CADERNO DE MAPA – SAFRA 25’26
UNIDADE PASSOS FORNECEDOR

IPIRANGA
AGROINDUSTRIAL

UNIDADE MOCOCA

Rodovia SP 338, Km 287, s/n
Fazenda Santa Emília, Mococa - SP
CEP: 13730-971

+55 (019) 3666-7000

UNIDADE DESCALVADO

Estrada Municipal Guilherme Scatena,
s/n - Zona Rural, Descalvado - SP
CEP: 13690-000

+55 (019) 3590-1000

UNIDADE IACANGA

Rod. Cezário José de Castilho, Fazenda
Nova, s/n – Zona Rural, Iacanga – SP
CEP: 17180-000

+55 (014) 3294-9000

UNIDADE PASSOS

Rod. MGC 146, Dep. Humberto de Almeida,
s/n, Faz. Soledade, Zona Rural, Passos – MG
CEP: 37900-970

LISTAGEM DE FAZENDA		
CÓDIGO	DESCRIÇÃO	ÁREA
522	SANTA MARIA I	258,49
523	SAO SEBASTIAO_A	28,58
524	SANTA CRUZ	103,46
525	BARRA SAO SEBASTIAO	236,44
526	SAO SEBASTIAO_B	745,36
527	SANTA MARIA II	236,48
533	SITIO ALTO DAS BELEZAS	18,21
534	SERRINHA (BELEZA II)	33,49
535	SERRINHA/FLAMBOYANT PORTO PEDRA	23,65
538	SANTOS REIS	54,72
539	TRES PORTEIRAS	77,24
540	NOVO HORIZONTE	74,99
543	INDAIA I	8,22
545	NOVA BARRA I	16,27
548	ATE VER	94,19
550	NOSSA SENHORA DA ROSA MISTICA	209,99
552	CASA BRANCA	45,76
553	CASA BRANCA B	22,03
554	BERALDINHOII	21,48
555	RIBEIRÃO GRANDE	45,60
556	BOM JESUS DA LAPA	5,79
557	CAMPOS/SERRINHA	72,79
558	FLORESTA	42,81
559	SAO FRANCISCO	45,93
560	CONQUISTA	113,31
561	BOCA DA MATA	29,03
562	BARRO PRETO	23,11
563	ESTIVA	78,89
564	SAO SEBASTIAO II	56,80
565	SANTO ANTONIO DE PADUA	15,24
566	TAGUAUNA II	139,50
567	RECANTO FORMOSO	31,28
568	JAU	62,39
569	SANTO ANTONIO	227,20
570	SANTA TEREZINHA	108,41
571	SALGADEIRA	152,63
572	SANTA MARIA III	151,42
573	ENGENHO DE SERRA	163,48
574	SAO SEBASTIAO III	64,65
575	ALVORADA/MANGUEIRA	76,92
576	AGUA SERENA	40,06
577	TRES IRMAOS	11,10
578	BOA VISTA II	88,25
579	LAVRINHA	39,37
580	MANGUEIRA II	27,32
582	MANGUEIRA III	22,40
583	SERRINHA II	13,19
584	NOVA BARRA II	27,13
585	SANTA CRUZ II	65,17
586	BARRA DA EXTREMA	120,49
587	MATA VIRGEM	78,08
588	JOIA DO RIO GRANDE	42,38
589	ROSA MISTICA II	73,20
590	SANTO ANTONIO PADEIRINHO	39,70
591	CAMPO REDONDO	150,89
592	SAO SEBASTIAO JACI	67,16
593	SANTA MARIA/ SANTA LUCIA	91,19
595	MARINHEIRO	44,46
596	SANTA MARIA V	41,42
597	MANDIOCA	19,52
598	BELA VISTA II	14,34
Total Geral		5.133,05

N: 7737660.23702131
E: 327548.36704815
LAT: −20°27'7.6386709" (−20.45212185302)
LONG: −46°39'12.8579566" (−46.65357165460)

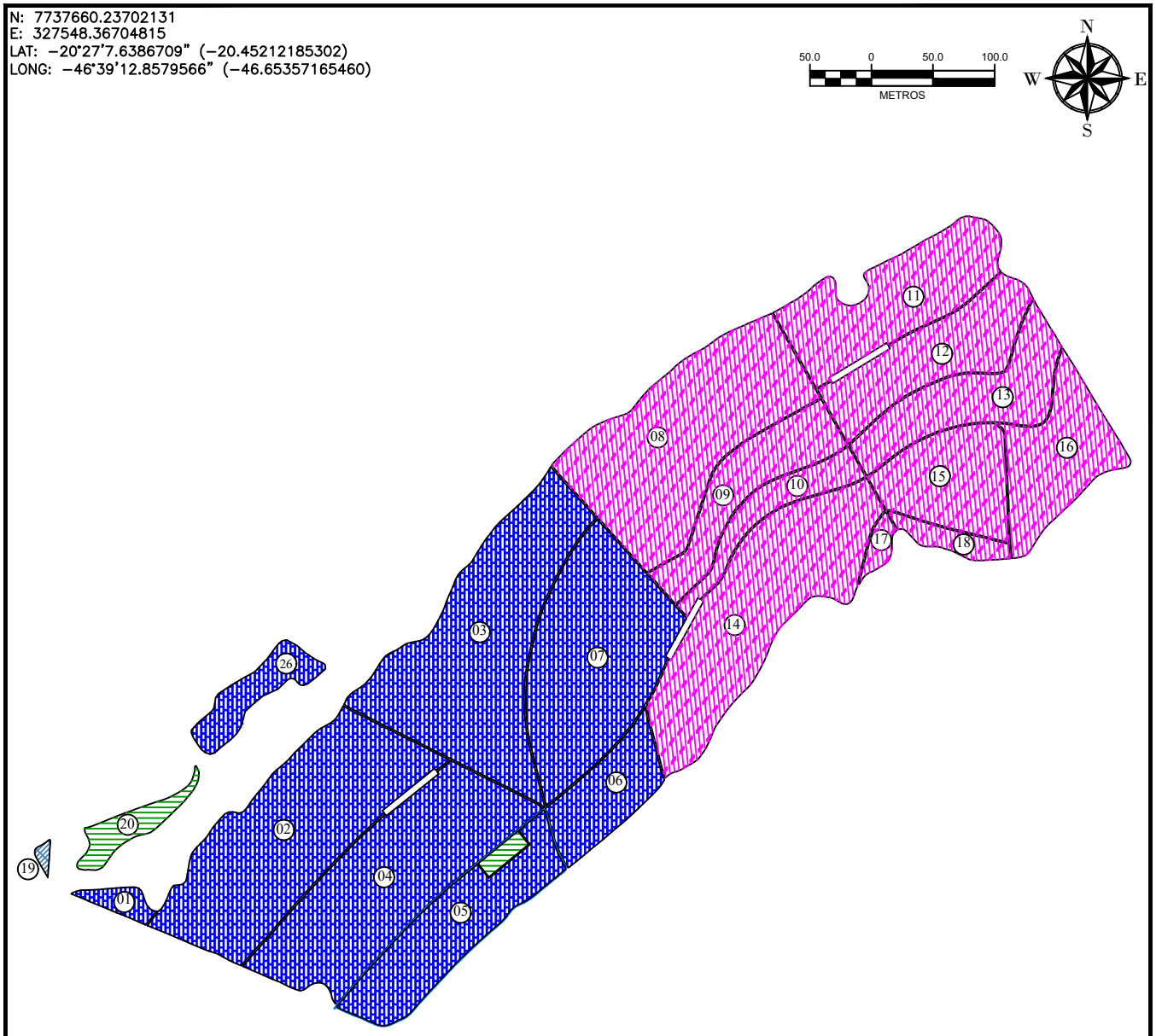

VIVEIRO
CTC -2994
RB 00-5014
RB 97-5033
IAC SP 01-5503

TABELA DE VARIEDADE	
VARIEDADE	ÁREA
CTC2994	124,91
IACSP01-5503	1,42
RB005014	129,70
RB975033	1,68
VIVEIRO	0,78
Total Geral	**258,49**

IPIRANGA AGROINDUSTRIAL

PROJETO: CADERNO DE MAPA 25'26	DATA: 16/06/2025	ESCALA: 1:5000	TOPÓGRAFO: LUÍS DUARTE
FAZENDA: 522 - SANTA MARIA I	MUNICÍPIO: PASSOS - MG		ÁREA (ha): 258,49
PROPRIETÁRIO: PAULO RODRIGUES	UNIDADE: IPIRANGA PASSOS S.A.		

Caderno de Mapas

Bloco	Talhao	Variedade	Estágio de Corte	Amb. Prod.	Data Plantio	Último Corte	Área (ha)	Estimativas Área (ha)	Finalid	Produt.	Prod. Total	Dist.	Esp.	Tipo Corte	Experimento
3 · REG 3			**522 · SANTA MARIA I**				**PAULO DE ARAUJO RODRIGUES E OUTROS**								
1	1	RB005014	2C	NC	11/11/23	19/09/25	1,39	1,39	1-MO.	100,0	139,00	42,4	1,5	MEC.	
1	2	RB005014	2C	NC	11/11/23	19/09/25	27,30	27,30	1-MO.	120,0	3.276,00	42,4	1,5	MEC.	
1	3	RB005014	2C	NC	03/04/23	19/09/25	29,14	29,14	1-MO.	120,0	3.496,80	42,4	1,5	MEC.	
1	4	RB005014	2C	NC	04/04/23	19/09/25	24,20	24,20	1-MO.	115,0	2.783,00	42,4	1,5	MEC.	
1	5	RB005014	FORM	IN	17/04/25		12,86	0,00	.		0,00	42,4	1,5	N/D	
1	5	VIVEIRO	FORM	IN	17/04/25		0,78	0,00	.		0,00	42,4	1,5	N/D	
1	6	RB005014	2C	NC	30/03/23	19/09/25	7,30	7,30	1-MO.	120,0	876,00	42,4	1,5	MEC.	
1	7	RB005014	2C	NC	30/03/23	19/09/25	23,24	23,24	1-MO.	120,0	2.788,80	42,4	1,5	MEC.	
1	8	CTC2994	2C	NC	20/11/23	30/09/25	26,58	26,58	1-MO.	120,0	3.189,60	42,4	1,5	MEC.	
1	9	CTC2994	2C	NC	05/03/23	30/09/25	8,94	8,94	1-MO.	120,0	1.072,80	42,4	1,5	MEC.	
1	10	CTC2994	2C	NC	04/04/23	30/09/25	4,63	4,63	1-MO.	120,0	555,60	42,4	1,5	MEC.	
1	11	CTC2994	2C	NC	20/11/23	30/09/25	14,81	14,81	1-MO.	120,0	1.777,20	42,4	1,5	MEC.	
1	12	CTC2994	2C	NC	05/03/23	30/09/25	11,51	11,51	1-MO.	120,0	1.381,20	42,4	1,5	MEC.	
1	13	CTC2994	2C	NC	05/04/23	30/09/25	10,58	10,58	1-MO.	120,0	1.269,60	42,4	1,5	MEC.	
1	14	CTC2994	2C	NC	05/04/23	30/09/25	23,78	23,78	1-MO.	120,0	2.853,60	42,4	1,5	MEC.	
1	15	CTC2994	2C	NC	06/04/23	30/09/25	10,08	10,08	1-MO.	120,0	1.209,60	42,4	1,5	MEC.	
1	16	CTC2994	2C	NC	07/04/23	30/09/25	10,86	10,86	1-MO.	120,0	1.303,20	42,4	1,5	MEC.	
1	17	CTC2994	2C	NC	08/04/23	30/09/25	1,03	1,03	1-MO.	120,0	123,60	42,4	1,5	MEC.	
1	18	CTC2994	2C	NC	05/04/23	30/09/25	2,11	2,11	1-MO.	120,0	253,20	42,4	1,5	MEC.	
1	19	RB975033	2C	NC	05/04/23	15/07/25	0,28	0,28	1-MO.	100,0	28,00	42,4	1,5	MEC.	
1	20	IACSP01-5503	2C	NC	05/04/23	15/07/25	1,42	1,42	1-MO.	100,0	142,00	42,4	1,5	MEC.	
1	20	RB975033	2C	NC	05/04/23	15/07/25	1,40	1,40	1-MO.	100,0	140,00	42,4	1,5	MEC.	
1	26	RB005014	2C	NC	29/11/23	07/08/25	4,27	4,27	1-MO.	100,0	427,00	42,4	1,5	MEC.	
Total/Média (3 / 522 · SANTA MARIA I)							258,49	244,85		118,8	29.085,80				

N: 7733023.15388097
E: 326431.07249322
LAT: −20°29'36.6174668" (−20.49350485189)
LONG: −46°39'51.6483739" (−46.66434677053)

50.0 0 50.0 100.0
METROS

N
W E
S

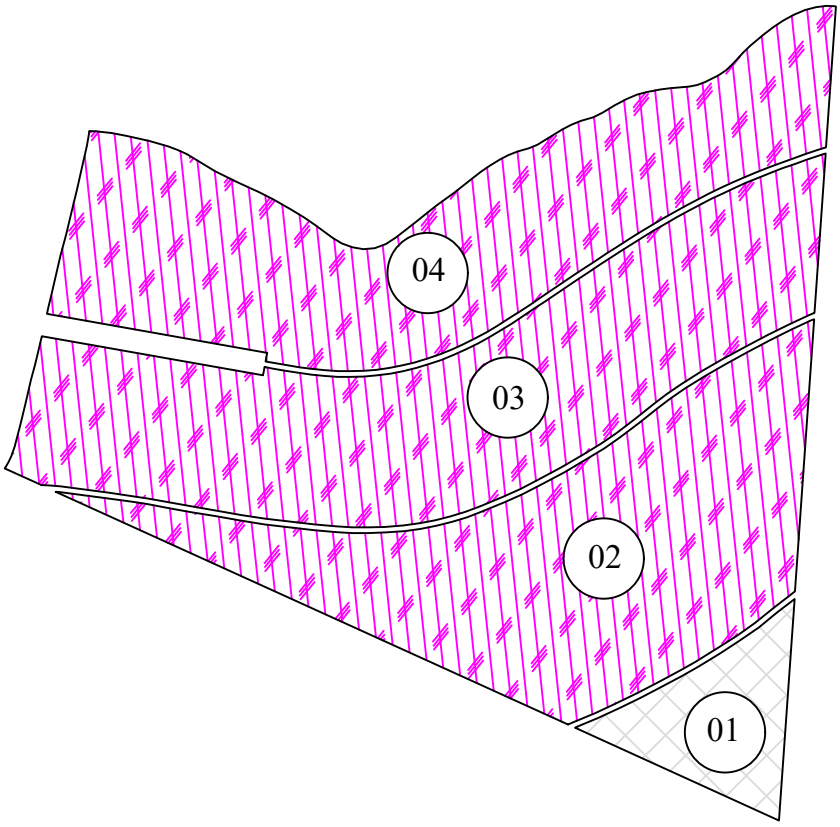

CTC - 4

CTC -2994

TABELA DE VARIEDADE	
VARIEDADE	ÁREA
CTC2994	26,93
CTC4	1,65
Total Geral	28,58

IPIRANGA AGROINDUSTRIAL

PROJETO: CADERNO DE MAPA 25'26	DATA: 15/10/2025	ESCALA: 1:5000	TOPÓGRAFO: LUIS DUARTE
FAZENDA: 523 - SÃO SEBASTIÃO	MUNICÍPIO: DELFINOPOLIS		ÁREA (ha): 28,58
PROPRIETÁRIO: PAULO RODRIGUES	UNIDADE: PASSOS MG		

Caderno de Mapas

Bloco	Talhao	Variedade	Estágio de Corte	Amb. Prod.	Data Plantio	Último Corte	Área (ha)	Estimativas Área (ha)	Finalid	Produt.	Prod. Total	Dist.	Esp.	Tipo Corte	Experimento
3 · REG 3			**523 · SAO SEBASTIAO_A**				**PAULO DE ARAUJO RODRIGUES E OUTROS**								
1	1	CTC4	4C	NC	01/04/21	07/08/25	1,65	1,65	1-MO.	100,0	165,00	39	1,5	MEC.	
1	2	CTC2994	3C	NC	05/04/22	27/10/25	8,57	8,57	1-MO.	93,0	797,01	39	1,5	MEC.	
1	3	CTC2994	3C	NC	05/04/22	27/10/25	9,55	9,55	1-MO.	93,0	888,15	39	1,5	MEC.	
1	4	CTC2994	3C	NC	05/04/22	27/10/25	8,81	8,81	1-MO.	93,0	819,33	39	1,5	MEC.	
Total/Média (3 / 523 · SAO SEBASTIAO_A)							28,58	28,58		93,4	2.669,49				

N: 7742136.28685185
E: 317898.93785723
LAT: −20°24'37.4102970" (−20.41039174918)
LONG: −46°44'42.7316455" (−46.74520323487)

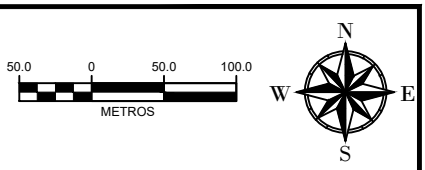

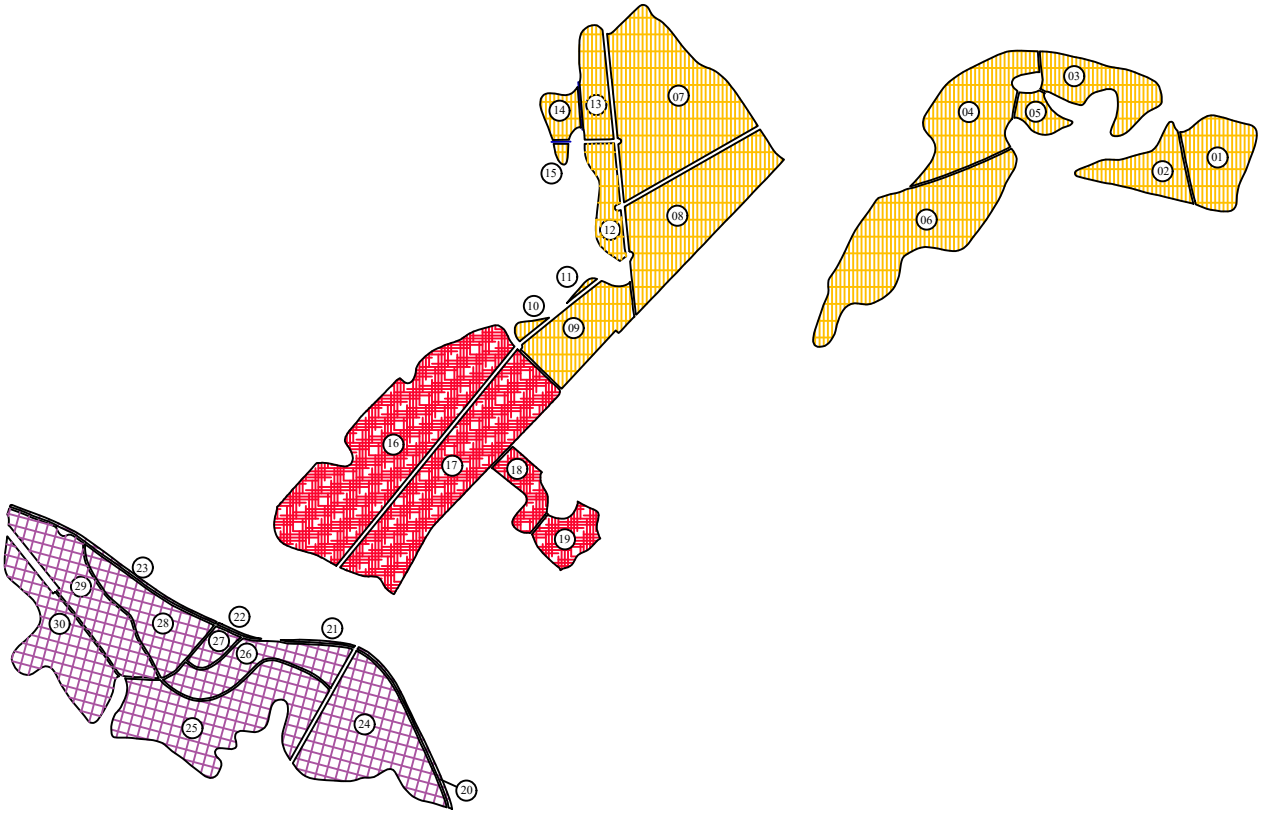

RB 98-5476

IAC CTC 07-8008

IAC SP 01-5503

TABELA DE VARIEDADE	
VARIEDADE	ÁREA
IACCTC07-8008	31,43
IACSP01-5503	23,74
RB985476	48,29
Total Geral	**103,46**

IPIRANGA AGROINDUSTRIAL

PROJETO: CADERNO DE MAPA 25'26	DATA: 08-07-2025	ESCALA: 1:5000	TOPÓGRAFO: CRISTIAN
FAZENDA: 524 - SANTA CRUZ	MUNICÍPIO: DELFINOPOLIS		ÁREA (ha): 103,46
PROPRIETÁRIO: PAULO RODRIGUES	UNIDADE: PASSOS MG		

Caderno de Mapas

Bloco	Talhao	Variedade	Estágio de Corte	Amb. Prod.	Data Plantio	Último Corte	Área (ha)	Estimativas Área (ha)	Finalid	Produt.	Prod. Total	Dist.	Esp.	Tipo Corte	Experimento
3 · REG 3			**524 · STA CRUZ**				**PAULO DE ARAUJO RODRIGUES E OUTROS**								
1	1	RB985476	1C	NC	27/04/24	05/04/25	3,17	3,17	2-MU.	70,0	221,90	51,4	1,5	MEC.	
1	2	RB985476	1C	NC	27/04/24	05/04/25	2,46	2,46	2-MU.	70,0	172,20	51,4	1,5	MEC.	
1	3	RB985476	1C	NC	28/04/24	05/04/25	2,99	2,99	2-MU.	70,0	209,30	51,4	1,5	MEC.	
1	4	RB985476	1C	NC	28/04/24	02/07/25	5,14	5,14	1-MO.	110,0	565,40	51,4	1,5	MEC.	
1	5	RB985476	1C	NC	28/04/24	02/07/25	0,87	0,87	1-MO.	110,0	95,70	51,4	1,5	MEC.	
1	6	RB985476	1C	NC	29/04/24	02/07/25	8,16	8,16	1-MO.	110,0	897,60	51,4	1,5	MEC.	
1	7	RB985476	1C	NC	09/04/24	12/09/25	9,87	9,87	1-MO.	95,0	937,65	51,4	1,5	MEC.	
1	8	RB985476	1C	NC	09/04/24	12/09/25	7,22	7,22	1-MO.	95,0	685,90	51,4	1,5	MEC.	
1	9	RB985476	1C	NC	04/04/24	12/09/25	3,60	3,60	1-MO.	95,0	342,00	51,4	1,5	MEC.	
1	10	RB985476	1C	NC	05/04/24	12/09/25	0,20	0,20	1-MO.	95,0	19,00	51,4	1,5	MEC.	
1	11	RB985476	1C	NC	04/04/24	12/09/25	0,07	0,07	1-MO.	95,0	6,65	51,4	1,5	MEC.	
1	12	RB985476	1C	NC	04/04/24	12/09/25	1,65	1,65	1-MO.	95,0	156,75	51,4	1,5	MEC.	
1	13	RB985476	1C	NC	04/04/24	12/09/25	1,84	1,84	1-MO.	95,0	174,80	51,4	1,5	MEC.	
1	14	RB985476	1C	NC	06/04/24	12/09/25	0,91	0,91	1-MO.	95,0	86,45	51,4	1,5	MEC.	
1	15	RB985476	1C	NC	05/04/24	12/09/25	0,14	0,14	1-MO.	95,0	13,30	51,4	1,5	MEC.	
1	16	IACSP01-5503	FORM	NC	18/01/25		11,97	11,97	1-MO.	85,0	1.017,45	51,4	1,5	MEC.	
1	17	IACSP01-5503	FORM	NC	18/01/25		8,76	8,76	1-MO.	85,0	744,60	51,4	1,5	MEC.	
1	18	IACSP01-5503	1C	NC	03/04/24	02/07/25	1,38	1,38	1-MO.	120,0	165,60	51,4	1,5	MEC.	
1	19	IACSP01-5503	1C	NC	02/04/24	02/07/25	1,63	1,63	1-MO.	120,0	195,60	51,4	1,5	MEC.	
1	20	IACCTC07-8008	1C	NC	10/04/24	17/09/25	0,27	0,27	1-MO.	110,0	29,70	51,4	1,5	MEC.	
1	21	IACCTC07-8008	1C	NC	10/04/24	17/09/25	0,08	0,08	1-MO.	110,0	8,80	51,4	1,5	MEC.	
1	22	IACCTC07-8008	1C	NC	11/04/24	17/09/25	0,05	0,05	1-MO.	110,0	5,50	51,4	1,5	MEC.	
1	23	IACCTC07-8008	1C	NC	01/05/24	17/09/25	0,36	0,36	1-MO.	110,0	39,60	51,4	1,5	MEC.	
1	24	IACCTC07-8008	1C	NC	01/05/24	17/09/25	6,93	6,61	1-MO.	110,0	727,10	51,4	1,5	MEC.	
1	24	IACCTC07-8008	1C	NC	01/05/24	17/09/25	6,93	0,32	2-MU.	70,0	22,40	51,4	1,5	MEC.	
1	25	IACCTC07-8008	1C	NC	11/04/24	17/09/25	7,50	4,81	2-MU.	70,0	336,70	51,4	1,5	MEC.	
1	25	IACCTC07-8008	1C	NC	11/04/24	17/09/25	7,50	2,69	1-MO.	110,0	295,90	51,4	1,5	MEC.	
1	26	IACCTC07-8008	1C	NC	11/04/24		3,04	3,04	2-MU.	70,0	212,80	51,4	1,5	MEC.	
1	27	IACCTC07-8008	1C	NC	01/05/24	17/09/25	0,65	0,65	1-MO.	110,0	71,50	51,4	1,5	MEC.	
1	28	IACCTC07-8008	1C	NC	13/04/24	17/09/25	3,36	3,36	1-MO.	110,0	369,60	51,4	1,5	MEC.	
1	29	IACCTC07-8008	1C	NC	10/04/24	17/09/25	4,46	4,46	1-MO.	110,0	490,60	51,4	1,5	MEC.	
1	30	IACCTC07-8008	1C	NC	10/04/24	17/09/25	4,73	2,77	2-MU.	70,0	193,90	51,4	1,5	MEC.	
1	30	IACCTC07-8008	1C	NC	10/04/24	17/09/25	4,73	1,96	1-MO.	110,0	215,60	51,4	1,5	MEC.	
Total/Média (3 / 524 · STA CRUZ)							103,46	103,46		94,0	9.727,55				

N: 7731594.32770704
E: 327027.38630923
LAT: −20°30'23.2748391" (−20.50646523309)
LONG: −46°39'31.5700173" (−46.65876944924)

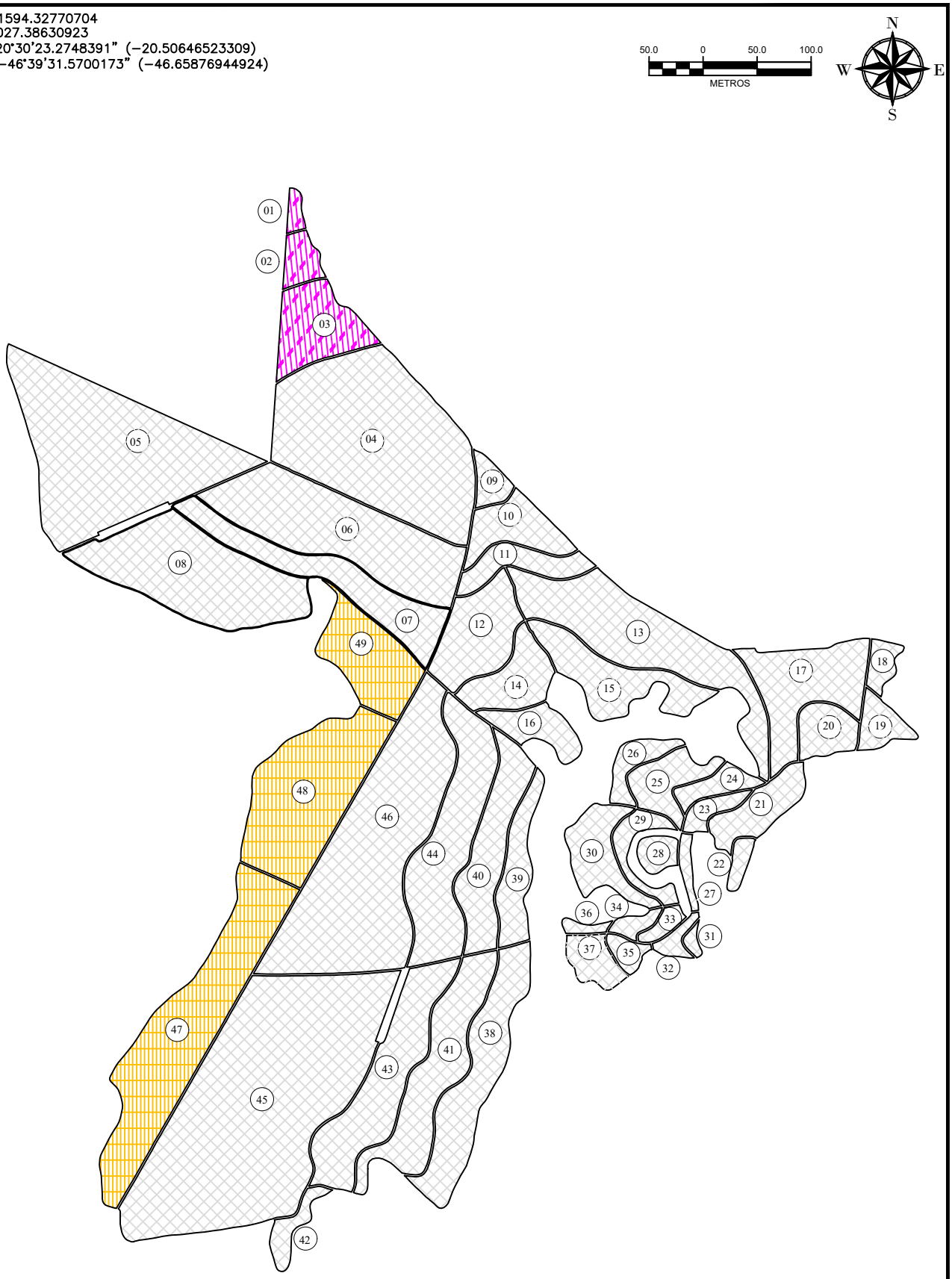

RB 98-5476
CTC -2994
CTC - 4

TABELA DE VARIEDADE	
VARIEDADE	Soma de Área Líquida
CTC2994	5,50
CTC4	203,08
RB985476	27,72
Total Geral	**236,30**

IPIRANGA AGROINDUSTRIAL

PROJETO: CADERNO DE MAPA 25'26	DATA: 23/06/2025	ESCALA: 1:5000	TOPÓGRAFO: CRISTIAN
FAZENDA: 525 - SERRINHA SÃO SEBASTIÃO	MUNICÍPIO: DELFINÓPOLIS		ÁREA (ha): 236,30
PROPRIETÁRIO: PAULO RODRIGUES	UNIDADE: PASSOS MG		

Caderno de Mapas

Bloco	Talhao	Variedade	Estágio de Corte	Amb. Prod.	Data Plantio	Último Corte	Área (ha)	Estimativas Área (ha)	Finalid	Produt.	Prod. Total	Dist.	Esp.	Tipo Corte	Experimento
3 · REG 3			525 · BARRA S SEBAS				PAULO DE ARAUJO RODRIGUES E OUTROS								
1	1	CTC2994	3C	NC	01/04/22	27/10/25	0,40	0,40	1-MO.	93,0	37,20	36,6	1,5	MEC.	
1	2	CTC2994	3C	NC	01/04/22	27/10/25	1,12	1,12	1-MO.	93,0	104,16	36,6	1,5	MEC.	
1	3	CTC2994	3C	NC	01/04/22	27/10/25	3,98	3,98	1-MO.	93,0	370,14	36,6	1,5	MEC.	
1	4	CTC4	5C	NC	01/04/20	07/08/25	17,79	17,79	1-MO.	92,0	1.636,68	36,6	1,5	MEC.	
1	5	CTC4	5C	NC	01/04/20	07/08/25	16,78	16,78	1-MO.	92,0	1.543,76	36,6	1,5	MEC.	
1	6	CTC4	5C	NC	01/04/20	07/08/25	11,09	11,09	1-MO.	92,0	1.020,28	36,6	1,5	MEC.	
1	7	CTC4	5C	NC	01/04/20	25/08/24	5,74	0,00	.		0,00	36,6	1,5	N/D	
1	8	CTC4	5C	NC	01/04/20	07/08/25	10,49	10,49	5-OU.	50,0	524,50	36,6	1,5	MEC.	
1	9	CTC4	3C	NC	01/04/22	12/09/25	0,92	0,92	1-MO.	95,0	87,40	36,6	1,5	MEC.	
1	10	CTC4	3C	NC	01/04/22	12/09/25	2,77	2,77	1-MO.	95,0	263,15	36,6	1,5	MEC.	
1	11	CTC4	3C	NC	01/04/22	12/09/25	2,07	2,07	1-MO.	95,0	196,65	36,6	1,5	MEC.	
1	12	CTC4	3C	NC	01/04/22	12/09/25	4,45	4,45	1-MO.	95,0	422,75	36,6	1,5	MEC.	
1	13	CTC4	3C	NC	01/04/22	12/09/25	9,82	9,82	1-MO.	95,0	932,90	36,6	1,5	MEC.	
1	14	CTC4	3C	NC	01/04/22	12/09/25	2,91	2,91	1-MO.	95,0	276,45	36,6	1,5	MEC.	
1	15	CTC4	3C	NC	01/04/22	12/09/25	4,54	4,54	1-MO.	95,0	431,30	36,6	1,5	MEC.	
1	16	CTC4	3C	NC	01/04/22	12/09/25	1,99	1,99	1-MO.	95,0	189,05	36,6	1,5	MEC.	
1	17	CTC4	3C	NC	01/04/22	12/09/25	5,76	5,76	1-MO.	95,0	547,20	36,6	1,5	MEC.	
1	18	CTC4	3C	NC	01/04/22	12/09/25	0,85	0,85	1-MO.	95,0	80,75	36,6	1,5	MEC.	
1	19	CTC4	3C	NC	01/04/22	12/09/25	1,34	1,34	1-MO.	95,0	127,30	36,6	1,5	MEC.	
1	20	CTC4	3C	NC	01/04/22	12/09/25	1,85	1,85	1-MO.	95,0	175,75	36,6	1,5	MEC.	
1	21	CTC4	3C	NC	01/04/22	12/09/25	2,51	2,51	1-MO.	95,0	238,45	36,6	1,5	MEC.	
1	22	CTC4	3C	NC	01/04/22	12/09/25	0,58	0,58	1-MO.	95,0	55,10	36,6	1,5	MEC.	
1	23	CTC4	3C	NC	01/04/22	12/09/25	0,82	0,82	1-MO.	95,0	77,90	36,6	1,5	MEC.	
1	24	CTC4	3C	NC	01/04/22	12/09/25	1,16	1,16	1-MO.	95,0	110,20	36,6	1,5	MEC.	
1	25	CTC4	3C	NC	01/04/22	12/09/25	2,29	2,29	1-MO.	95,0	217,55	36,6	1,5	MEC.	
1	26	CTC4	3C	NC	01/04/22	12/09/25	1,30	1,30	1-MO.	95,0	123,50	36,6	1,5	MEC.	
1	27	CTC4	3C	NC	01/04/22	12/09/25	0,52	0,52	1-MO.	95,0	49,40	36,6	1,5	MEC.	
1	28	CTC4	3C	NC	01/04/22	12/09/25	0,85	0,85	1-MO.	95,0	80,75	36,6	1,5	MEC.	
1	29	CTC4	3C	NC	01/04/22	12/09/25	1,37	1,37	1-MO.	95,0	130,15	36,6	1,5	MEC.	
1	30	CTC4	3C	NC	01/04/22	12/09/25	2,95	2,95	1-MO.	95,0	280,25	36,6	1,5	MEC.	
1	31	CTC4	3C	NC	01/04/22	12/09/25	0,23	0,23	1-MO.	95,0	21,85	36,6	1,5	MEC.	
1	32	CTC4	3C	NC	01/04/22	12/09/25	0,56	0,56	1-MO.	95,0	53,20	36,6	1,5	MEC.	
1	33	CTC4	3C	NC	01/04/22	12/09/25	0,54	0,54	1-MO.	95,0	51,30	36,6	1,5	MEC.	
1	34	CTC4	3C	NC	01/04/22	12/09/25	0,54	0,54	1-MO.	95,0	51,30	36,6	1,5	MEC.	
1	35	CTC4	3C	NC	01/04/22	12/09/25	0,67	0,67	1-MO.	95,0	63,65	36,6	1,5	MEC.	
1	36	CTC4	3C	NC	01/04/22	12/09/25	0,32	0,32	1-MO.	95,0	30,40	36,6	1,5	MEC.	
1	37	CTC4	3C	NC	01/04/22	12/09/25	1,48	1,48	1-MO.	95,0	140,60	36,6	1,5	MEC.	
1	38	CTC4	3C	NC	01/04/22	11/09/25	6,60	6,60	1-MO.	75,0	495,00	36,6	1,5	MEC.	
1	39	CTC4	3C	NC	01/04/22	11/09/25	2,68	2,68	1-MO.	75,0	201,00	36,6	1,5	MEC.	

Caderno de Mapas

Bloco	Talhao	Variedade	Estágio de Corte	Amb. Prod.	Data Plantio	Data Último Corte	Área (ha)	Estimativas Área (ha)	Estimativas Finalid	Estimativas Produt.	Prod. Total	Dist.	Esp.	Tipo Corte	Experimento
1	40	CTC4	3C	NC	01/04/22	11/09/25	4,81	4,81	1-MO.	75,0	360,75	36,6	1,5	MEC.	
1	41	CTC4	3C	NC	01/04/22	11/09/25	6,48	6,48	1-MO.	75,0	486,00	36,6	1,5	MEC.	
1	42	CTC4	3C	NC	01/04/22	11/09/25	1,07	1,07	1-MO.	75,0	80,25	36,6	1,5	MEC.	
1	43	CTC4	3C	NC	01/04/22	11/09/25	7,26	7,26	1-MO.	75,0	544,50	36,6	1,5	MEC.	
1	44	CTC4	3C	NC	01/04/22	11/09/25	8,01	8,01	1-MO.	75,0	600,75	36,6	1,5	MEC.	
1	45	CTC4	3C	NC	01/04/22	11/09/25	28,54	28,54	1-MO.	90,0	2.568,60	36,6	1,5	MEC.	
1	46	CTC4	3C	NC	01/04/22	11/09/25	17,92	17,92	1-MO.	90,0	1.612,80	36,6	1,5	MEC.	
1	47	RB985476	3C	NC	01/04/22	31/10/24	12,84	12,84	1-MO.	80,0	1.027,20	36,6	1,5	MEC.	
1	48	RB985476	3C	NC	01/04/22	31/10/24	10,08	10,08	1-MO.	80,0	806,40	36,6	1,5	MEC.	
1	49	RB985476	3C	NC	01/04/22	31/10/24	4,80	4,80	1-MO.	80,0	384,00	36,6	1,5	MEC.	
Total/Média (3 / 525 · BARRA S SEBAS)							236,44	230,70		86,3	19.910,17				

N: 7734760.82221592
E: 325701.27107156
LAT: −20°28'39.8728886" (−20.47774246904)
LONG: −46°40'16.2209912" (−46.67117249756)

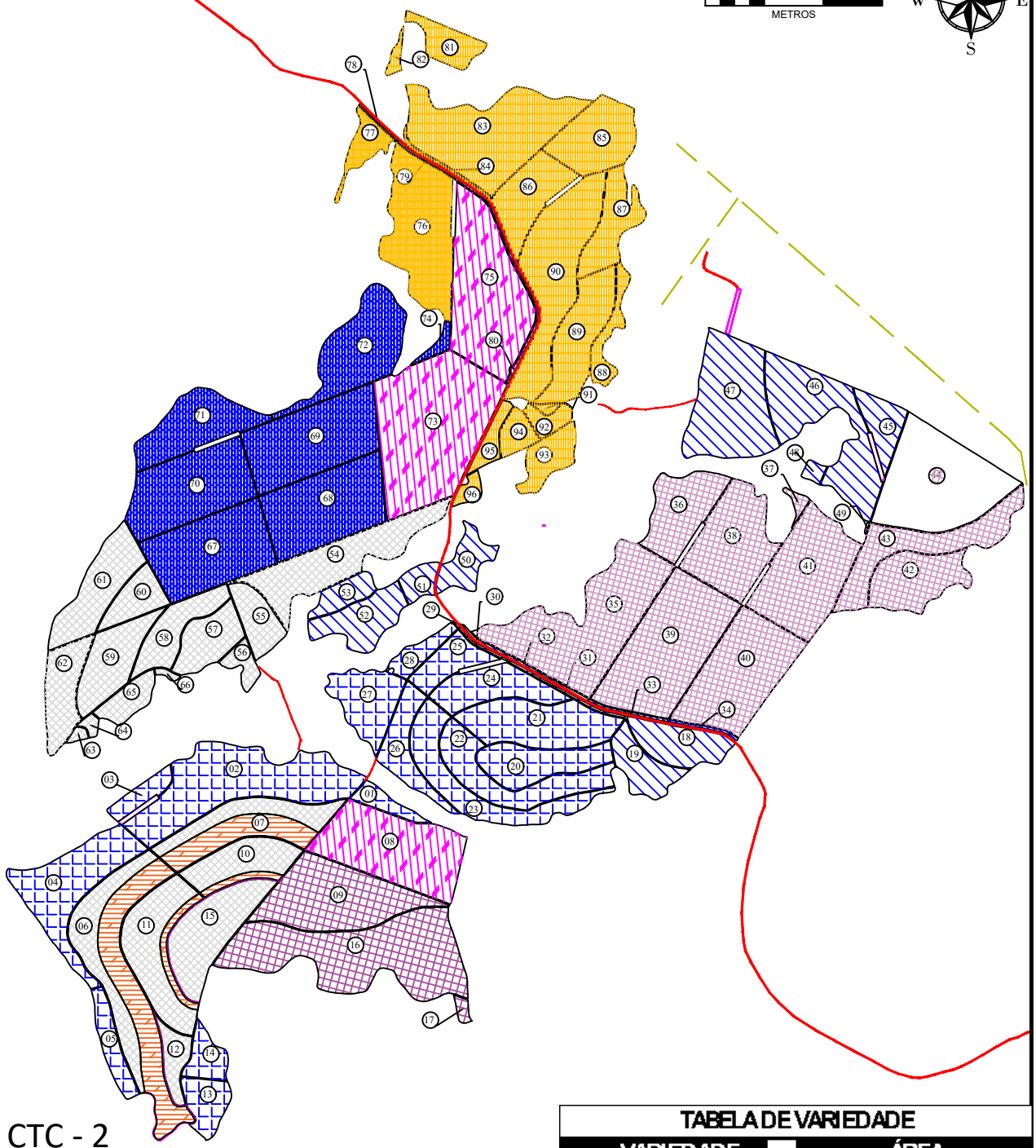

CTC - 2
CTC - 4
A DEFINIR
CTC -2994
RB 00-5014
RB 85-5156
RB 98-5476
CTC - 9001
RB 12-7825
IAC CTC 07-7207
IAC CTC 07-8008

TABELA DE VARIEDADE

VARIEDADE	ÁREA
CTC2	113,80
CTC2994	65,53
CTC4	107,88
CTC9001	22,53
IACCTC07-7207	96,73
IACCTC07-8008	17,92
RB005014	109,25
RB127825	1,84
RB855156	101,72
RB985476	108,16
Total Geral	**745,36**

IPIRANGA AGROINDUSTRIAL

PROJETO	DATA	ESCALA	TOPÓGRAFO
CADERNO DE MAPA 25'26	12-12-2023	1:5000	LUIS DUARTE
FAZENDA	**MUNICÍPIO**		**ÁREA (ha)**
526 - SÃO SEBASTIÃO	PASSOS MG		745,36
PROPRIETÁRIO	**UNIDADE**		
PAULO RODRIGUES	PASSOS MG		

Bloco	Talhao	Variedade	Estágio de Corte	Amb. Prod.	Data Plantio	Último Corte	Área (ha)	Estimativas Área (ha)	Finalid	Produt.	Prod. Total	Dist.	Esp.	Tipo Corte	Experimento
3 · REG 3			526 · SAO SEBASTIAO_B				PAULO DE ARAUJO RODRIGUES E OUTROS								
1	1	CTC2	1C	NC	15/10/24		2,01	2,01	5-OU.	70,0	140,70	38,9	1,5	MEC.	
1	2	CTC2	1C	NC	15/10/24		20,82	20,82	5-OU.	70,0	1.457,40	38,9	1,5	MEC.	
1	3	CTC2	1C	NC	15/10/24		2,38	2,38	5-OU.	70,0	166,60	38,9	1,5	MEC.	
1	4	CTC2	1C	NC	15/10/24		13,20	13,20	5-OU.	70,0	924,00	38,9	1,5	MEC.	
1	5	CTC2	1C	NC	15/10/24		3,48	3,48	5-OU.	70,0	243,60	38,9	1,5	MEC.	
1	6	CTC4	3C	NC	01/04/22	22/10/25	8,69	3,48	1-MO.	90,0	313,20	38,9	1,5	MEC.	
1	6	CTC9001	3C	NC	01/04/22	22/10/25	13,16	5,27	1-MO.	90,0	474,30	38,9	1,5	MEC.	
1	7	CTC4	3C	NC	01/04/22	22/10/25	5,90	3,10	5-OU.	50,0	155,00	38,9	1,5	MEC.	
1	7	CTC4	3C	NC	01/04/22	22/10/25	5,90	2,80	1-MO.	90,0	252,00	38,9	1,5	MEC.	
1	7	CTC9001	3C	NC	01/04/22	22/10/25	6,55	3,10	1-MO.	90,0	279,00	38,9	1,5	MEC.	
1	7	CTC9001	3C	NC	01/04/22	22/10/25	6,55	3,45	5-OU.	50,0	172,50	38,9	1,5	MEC.	
1	8	CTC2994	3C	NC	01/04/22	27/10/25	17,13	17,13	1-MO.	90,0	1.541,70	38,9	1,5	MEC.	
1	9	CTC2994	2C	NC	01/04/23	27/10/25	11,08	11,08	1-MO.	115,0	1.274,20	38,9	1,5	MEC.	
1	9	IACCTC07-8008	2C	NC	01/04/23	27/10/25	4,72	4,72	1-MO.	115,0	542,80	38,9	1,5	MEC.	
1	10	CTC4	3C	NC	01/04/22	22/10/25	6,63	5,76	1-MO.	90,0	518,40	38,9	1,5	MEC.	
1	10	CTC9001	3C	NC	01/04/22	22/10/25	1,03	0,90	1-MO.	90,0	81,00	38,9	1,5	MEC.	
1	11	CTC4	3C	NC	01/04/22	22/10/25	10,70	1,43	5-OU.	50,0	71,50	38,9	1,5	MEC.	
1	11	CTC4	3C	NC	01/04/22	22/10/25	10,70	9,27	1-MO.	90,0	834,30	38,9	1,5	MEC.	
1	11	CTC9001	3C	NC	01/04/22	22/10/25	1,79	1,55	1-MO.	90,0	139,50	38,9	1,5	MEC.	
1	11	CTC9001	3C	NC	01/04/22	22/10/25	1,79	0,24	5-OU.	50,0	12,00	38,9	1,5	MEC.	
1	12	CTC4	3C	NC	01/04/22	22/10/25	2,90	2,90	1-MO.	90,0	261,00	38,9	1,5	MEC.	
1	13	CTC2	1C	NC	15/10/24		3,88	3,88	5-OU.	70,0	271,60	38,9	1,5	MEC.	
1	14	CTC2	1C	NC	15/10/24		2,96	2,96	5-OU.	70,0	207,20	38,9	1,5	MEC.	
1	15	CTC4	3C	NC	01/04/22	22/10/25	10,90	10,90	1-MO.	90,0	981,00	38,9	1,5	MEC.	
1	16	CTC2994	3C	NC	01/04/22	27/10/25	12,72	12,72	1-MO.	95,0	1.208,40	38,9	1,5	MEC.	
1	16	IACCTC07-8008	3C	NC	01/04/22	27/10/25	12,63	12,63	1-MO.	95,0	1.199,85	38,9	1,5	MEC.	
1	17	IACCTC07-8008	3C	NC	01/04/22	27/10/25	0,57	0,57	1-MO.	95,0	54,15	38,9	1,5	MEC.	
1	18	RB855156	1C	NC	17/03/24	16/04/25	6,16	6,16	1-MO.	75,0	462,00	38,9	1,5	MEC.	
1	19	RB855156	1C	NC	17/03/24	16/04/25	4,92	4,92	1-MO.	100,0	492,00	38,9	1,5	MEC.	
1	20	CTC2	3C	NC	01/04/22	22/10/25	7,44	7,44	1-MO.	85,0	632,40	38,9	1,5	MEC.	
1	21	CTC2	3C	NC	01/04/22	22/10/25	11,52	11,52	1-MO.	85,0	979,20	38,9	1,5	MEC.	
1	22	CTC2	3C	NC	01/04/22	22/10/25	9,22	9,22	1-MO.	85,0	783,70	38,9	1,5	MEC.	
1	23	CTC2	3C	NC	01/04/22	22/10/25	9,87	9,87	1-MO.	85,0	838,95	38,9	1,5	MEC.	
1	24	CTC2	3C	NC	01/04/22	22/10/25	7,05	7,05	1-MO.	85,0	599,25	38,9	1,5	MEC.	
1	25	CTC2	3C	NC	01/04/22	16/02/24	4,19	4,19	5-OU.	70,0	293,30	38,9	1,5	MEC.	
1	26	CTC2	3C	NC	01/04/22	29/02/24	5,42	5,42	5-OU.	70,0	379,40	38,9	1,5	MEC.	
1	27	CTC2	3C	NC	01/04/22	15/08/25	7,17	7,17	1-MO.	80,0	573,60	38,9	1,5	MEC.	
1	28	CTC2	3C	NC	01/04/22	15/08/25	2,43	2,43	1-MO.	80,0	194,40	38,9	1,5	MEC.	
1	29	CTC2	3C	NC	01/04/22	22/10/25	0,03	0,03	1-MO.	75,0	2,25	38,9	1,5	MEC.	

Caderno de Mapas

Bloco	Talhao	Variedade	Estágio de Corte	Amb. Prod.	Data Plantio	Data Último Corte	Área (ha)	Estimativas Área (ha)	Estimativas Finalid	Estimativas Produt.	Prod. Total	Dist.	Esp.	Tipo Corte	Experimento
1	30	CTC2	3C	NC	01/04/22	22/10/25	0,21	0,21	1-MO.	75,0	15,75	38,9	1,5	MEC.	
1	31	CTC2	3C	NC	01/04/22	22/10/25	0,52	0,52	1-MO.	75,0	39,00	38,9	1,5	MEC.	
1	32	RB855156	1C	NC	15/03/24	07/04/25	0,60	0,60	1-MO.	100,0	60,00	38,9	1,5	MEC.	
1	33	RB855156	1C	NC	13/03/24	07/04/25	0,33	0,33	1-MO.	100,0	33,00	38,9	1,5	MEC.	
1	34	RB855156	1C	NC	13/03/24	07/04/25	0,31	0,31	1-MO.	100,0	31,00	38,9	1,5	MEC.	
1	35	IACCTC07-7207	1C	NC	13/03/24	07/04/25	1,77	1,77	1-MO.	100,0	177,00	38,9	1,5	MEC.	
1	35	RB127825	1C	NC	13/03/24	07/04/25	1,61	1,61	1-MO.	100,0	161,00	38,9	1,5	MEC.	
1	35	RB855156	1C	NC	13/03/24	07/04/25	19,51	19,51	1-MO.	100,0	1.951,00	38,9	1,5	MEC.	
1	36	IACCTC07-7207	1C	NC	13/03/24	07/04/25	8,72	8,72	1-MO.	100,0	872,00	38,9	1,5	MEC.	
1	37	IACCTC07-7207	1C	NC	13/03/24	07/04/25	0,63	0,63	1-MO.	100,0	63,00	38,9	1,5	MEC.	
1	38	IACCTC07-7207	1C	NC	13/03/24	07/04/25	12,86	12,86	1-MO.	100,0	1.286,00	38,9	1,5	MEC.	
1	39	IACCTC07-7207	1C	NC	13/03/24	07/04/25	21,24	21,24	1-MO.	100,0	2.124,00	38,9	1,5	MEC.	
1	40	IACCTC07-7207	1C	NC	11/03/24	04/04/25	16,53	16,53	1-MO.	100,0	1.653,00	38,9	1,5	MEC.	
1	41	IACCTC07-7207	1C	NC	04/03/24	04/04/25	15,88	15,88	1-MO.	100,0	1.588,00	38,9	1,5	MEC.	
1	42	IACCTC07-7207	2C	NC	01/04/23	22/04/25	8,47	8,47	1-MO.	90,0	762,30	38,9	1,5	MEC.	
1	43	IACCTC07-7207	2C	NC	01/04/23	22/04/25	10,41	10,41	1-MO.	90,0	936,90	38,9	1,5	MEC.	
1	44	IACCTC07-7207	2C	NC	01/04/23	16/04/25	0,22	0,22	1-MO.	105,0	23,10	38,9	1,5	MEC.	
1	44	RB127825	2C	NC	01/04/23	16/04/25	0,23	0,23	1-MO.	105,0	24,15	38,9	1,5	MEC.	
1	44	RB855156	2C	NC	01/04/23	16/04/25	18,83	18,83	1-MO.	105,0	1.977,15	38,9	1,5	MEC.	
1	45	RB855156	2C	NC	01/04/23	16/04/25	3,89	3,89	1-MO.	105,0	408,45	38,9	1,5	MEC.	
1	46	RB855156	2C	NC	01/04/23	24/04/25	15,00	15,00	1-MO.	105,0	1.575,00	38,9	1,5	MEC.	
1	47	RB855156	2C	NC	01/04/23	24/04/25	16,28	16,28	1-MO.	105,0	1.709,40	38,9	1,5	MEC.	
1	48	RB855156	2C	NC	01/04/23	24/04/25	0,69	0,69	1-MO.	105,0	72,45	38,9	1,5	MEC.	
1	49	RB855156	2C	NC	01/04/23	24/04/25	0,04	0,04	1-MO.	105,0	4,20	38,9	1,5	MEC.	
1	50	RB855156	3C	NC	01/04/22	05/05/25	3,89	3,89	1-MO.	85,0	330,65	38,9	1,5	MEC.	
1	51	RB855156	3C	NC	01/04/22	05/05/25	2,01	2,01	1-MO.	85,0	170,85	38,9	1,5	MEC.	
1	52	RB855156	3C	NC	01/04/22	05/05/25	6,47	6,47	1-MO.	85,0	549,95	38,9	1,5	MEC.	
1	53	RB855156	3C	NC	01/04/22	05/05/25	2,79	2,79	1-MO.	85,0	237,15	38,9	1,5	MEC.	
1	54	CTC4	3C	NC	01/04/22	16/09/25	13,10	13,10	1-MO.	90,0	1.179,00	38,9	1,5	MEC.	
1	55	CTC4	3C	NC	01/04/22	16/09/25	4,31	4,31	1-MO.	90,0	387,90	38,9	1,5	MEC.	
1	56	CTC4	3C	NC	01/04/22	16/09/25	1,82	1,82	1-MO.	90,0	163,80	38,9	1,5	MEC.	
1	57	CTC4	3C	NC	01/04/22	16/09/25	5,65	5,65	1-MO.	90,0	508,50	38,9	1,5	MEC.	
1	58	CTC4	3C	NC	01/04/22	16/09/25	5,94	5,94	1-MO.	90,0	534,60	38,9	1,5	MEC.	
1	59	CTC4	3C	NC	01/04/22	16/09/25	7,65	7,65	1-MO.	90,0	688,50	38,9	1,5	MEC.	
1	60	CTC4	3C	NC	01/04/22	16/09/25	4,08	4,08	1-MO.	90,0	367,20	38,9	1,5	MEC.	
1	61	CTC4	3C	NC	01/04/22	16/09/25	8,99	8,99	1-MO.	90,0	809,10	38,9	1,5	MEC.	
1	62	CTC4	3C	NC	01/04/22	16/09/25	6,32	6,32	1-MO.	90,0	568,80	38,9	1,5	MEC.	
1	63	CTC4	3C	NC	01/04/22	16/09/25	0,39	0,39	1-MO.	90,0	35,10	38,9	1,5	MEC.	
1	64	CTC4	3C	NC	01/04/22	16/09/25	0,53	0,53	1-MO.	90,0	47,70	38,9	1,5	MEC.	
1	65	CTC4	3C	NC	01/04/22	16/09/25	3,08	3,08	1-MO.	90,0	277,20	38,9	1,5	MEC.	
1	66	CTC4	3C	NC	01/04/22	16/09/25	0,30	0,30	1-MO.	90,0	27,00	38,9	1,5	MEC.	

Caderno de Mapas

Bloco	Talhao	Variedade	Estágio de Corte	Amb. Prod.	Data Plantio	Data Último Corte	Área (ha)	Estimativas Área (ha)	Estimativas Finalid	Estimativas Produt.	Prod. Total	Dist.	Esp.	Tipo Corte	Experimento
1	67	RB005014	1C	NC	14/02/24	09/07/25	15,48	15,48	1-MO.	125,0	1.935,00	38,9	1,5	MEC.	
1	68	RB005014	1C	NC	14/02/24	09/07/25	15,73	15,73	1-MO.	125,0	1.966,25	38,9	1,5	MEC.	
1	69	RB005014	1C	NC	26/02/24	09/07/25	16,54	16,54	1-MO.	125,0	2.067,50	38,9	1,5	MEC.	
1	70	RB005014	1C	NC	27/02/24	09/07/25	15,07	15,07	1-MO.	125,0	1.883,75	38,9	1,5	MEC.	
1	71	RB005014	1C	NC	27/02/24	09/07/25	9,75	9,75	1-MO.	125,0	1.218,75	38,9	1,5	MEC.	
1	72	RB005014	1C	NC	27/02/24	09/07/25	12,36	12,36	1-MO.	125,0	1.545,00	38,9	1,5	MEC.	
1	73	CTC2994	3C	NC	01/04/22	07/11/25	3,66	3,66	1-MO.	95,0	347,70	38,9	1,5	MEC.	
1	73	RB005014	3C	NC	01/04/22	07/11/25	23,48	23,48	1-MO.	95,0	2.230,60	38,9	1,5	MEC.	
1	74	RB005014	3C	NC	01/04/22	07/11/25	0,84	0,84	1-MO.	95,0	79,80	38,9	1,5	MEC.	
1	75	CTC2994	3C	NC	01/04/22	07/11/25	20,00	20,00	1-MO.	95,0	1.900,00	38,9	1,5	MEC.	
1	76	RB985476	1C	NC	29/02/24	09/07/25	15,81	15,81	1-MO.	125,0	1.976,25	38,9	1,5	MEC.	
1	77	RB985476	1C	NC	28/02/24	09/07/25	2,81	2,81	1-MO.	125,0	351,25	38,9	1,5	MEC.	
1	78	RB985476	1C	NC	28/02/24	09/07/25	0,18	0,18	1-MO.	125,0	22,50	38,9	1,5	MEC.	
1	79	RB985476	1C	NC	01/03/24	09/07/25	0,24	0,24	1-MO.	125,0	30,00	38,9	1,5	MEC.	
1	80	CTC2994	3C	NC	01/04/22	09/07/25	0,94	0,94	1-MO.	95,0	89,30	38,9	1,5	MEC.	
1	81	RB985476	1C	NC	29/02/24	09/07/25	3,81	3,81	1-MO.	125,0	476,25	38,9	1,5	MEC.	
1	82	RB985476	1C	NC	29/02/24	09/07/25	0,66	0,66	1-MO.	125,0	82,50	38,9	1,5	MEC.	
1	83	RB985476	1C	NC	28/02/24	09/07/25	20,20	20,20	1-MO.	125,0	2.525,00	38,9	1,5	MEC.	
1	84	RB985476	1C	NC	29/02/24		0,44	0,44	1-MO.	125,0	55,00	38,9	1,5	MEC.	
1	85	RB985476	3C	NC	01/04/22	07/11/25	8,86	8,86	1-MO.	75,0	664,50	38,9	1,5	MEC.	
1	86	RB985476	3C	NC	01/04/22	07/11/25	7,54	7,54	1-MO.	75,0	565,50	38,9	1,5	MEC.	
1	87	RB985476	3C	NC	01/04/22	07/11/25	6,22	6,22	1-MO.	75,0	466,50	38,9	1,5	MEC.	
1	88	RB985476	3C	NC	01/04/22	07/11/25	2,82	2,82	1-MO.	75,0	211,50	38,9	1,5	MEC.	
1	89	RB985476	3C	NC	01/04/22	07/11/25	9,60	9,60	1-MO.	75,0	720,00	38,9	1,5	MEC.	
1	90	RB985476	3C	NC	01/04/22	07/11/25	17,48	17,48	1-MO.	75,0	1.311,00	38,9	1,5	MEC.	
1	91	RB985476	2C	NC	01/04/23	07/11/25	0,33	0,33	1-MO.	85,0	28,05	38,9	1,5	MEC.	
1	92	RB985476	2C	NC	01/04/23	07/11/25	1,73	1,73	1-MO.	85,0	147,05	38,9	1,5	MEC.	
1	93	RB985476	2C	NC	01/04/23	07/11/25	4,06	4,06	1-MO.	85,0	345,10	38,9	1,5	MEC.	
1	94	RB985476	2C	NC	01/04/23	07/11/25	2,23	2,23	1-MO.	85,0	189,55	38,9	1,5	MEC.	
1	95	RB985476	2C	NC	01/04/23	07/11/25	2,04	2,04	1-MO.	85,0	173,40	38,9	1,5	MEC.	
1	96	RB985476	2C	NC	01/04/23	07/11/25	1,10	1,10	1-MO.	85,0	93,50	38,9	1,5	MEC.	
Total/Média (3 / 526 · SAO SEBASTIAO_B)							745,36	731,26		95,9	70.135,25				

N: 7738666.36113673
E: 326591.20047633
LAT: −20°26'33.1726089" (−20.44254794691)
LONG: −46°39'44.1462177" (−46.66226283824)

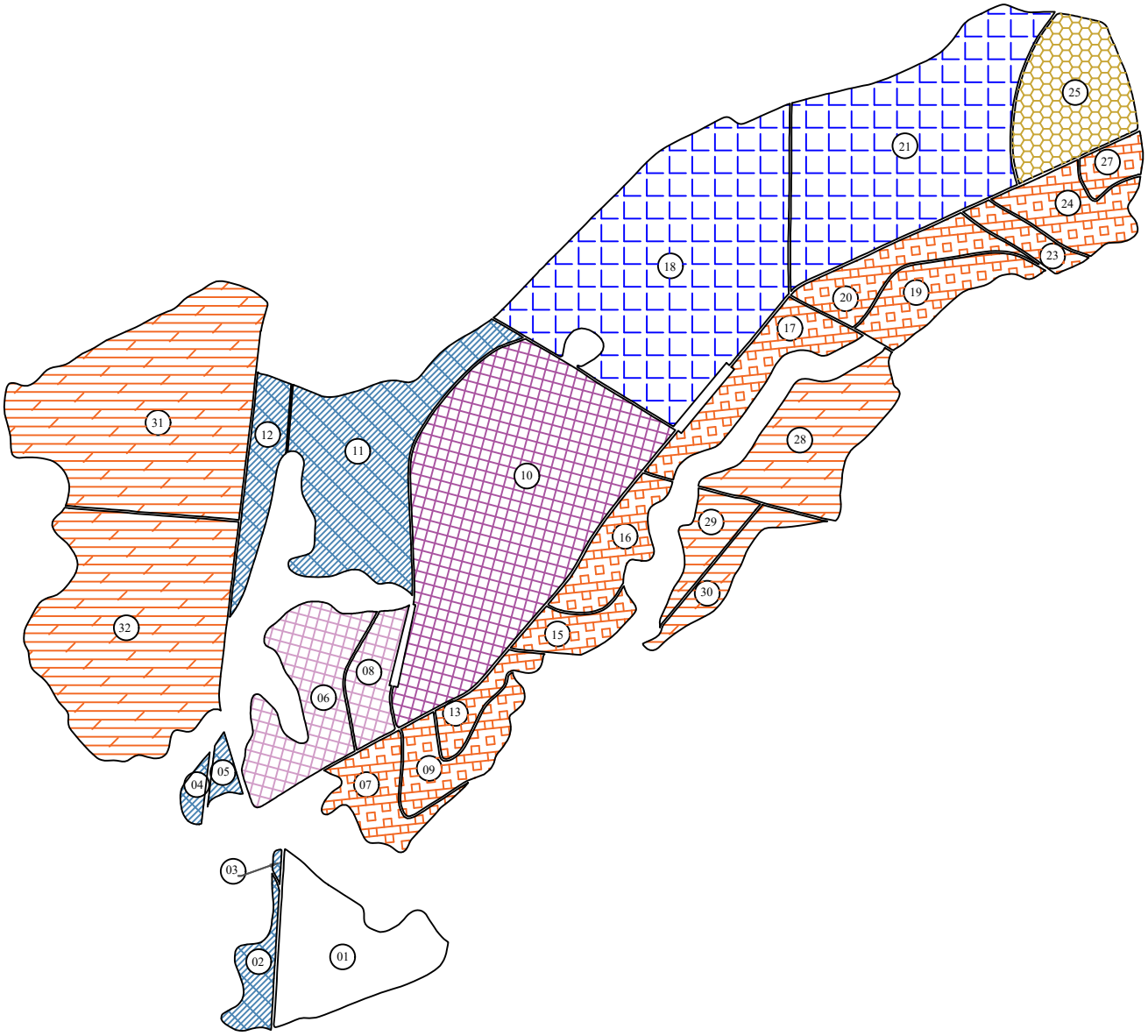

- A DEFINIR
- CTC - 2
- RB 12-7825
- CTC - 9001
- RB 97-5033
- IAC CTC 07-8008
- IAC CTC 07-7207
- CTC - 9003 BT

TABELA DE VARIEDADE

VARIEDADE	ÁREA
A DEFINIR	9,50
CTC-2	53,84
RB 97-5033	21,63
IAC CTC 07-7207	11,34
CTC-9003 BT	37,40
IAC CTC 07-8008	33,11
RB 12-7825	8,33
CTC-9001	61,33
Total Geral	**236,48**

IPIRANGA AGROINDUSTRIAL

PROJETO	DATA	ESCALA	TOPÓGRAFO
CADERNO DE MAPA 25'26	26/06/2025	1:5000	CRISTIAN

FAZENDA	MUNICÍPIO	ÁREA (ha)
527 - SANTA MARIA II	DELFINOPOLIS	236,48

PROPRIETÁRIO	UNIDADE
PAULO RODRIGUES	PASSOS MG

Caderno de Mapas

Bloco	Talhao	Variedade	Estágio de Corte	Amb. Prod.	Data Plantio	Último Corte	Área (ha)	Estimativas Área (ha)	Finalid	Produt.	Prod. Total	Dist.	Esp.	Tipo Corte	Experimento
3 · REG 3			**527 · SANTA MARIA II**				**PAULO DE ARAUJO RODRIGUES E OUTROS**								
1	1	IACSP01-5503	2C	NC	01/04/23	15/07/25	7,15	7,15	1-MO.	90,0	643,50	41	1,5	MEC.	
1	1	RB975033	2C	NC	01/04/23	15/07/25	2,35	2,35	1-MO.	90,0	211,50	41	1,5	MEC.	
1	2	RB975033	3C	NC	01/04/22	15/07/25	2,11	2,11	1-MO.	80,0	168,80	41	1,5	MEC.	
1	3	RB975033	2C	NC	01/04/23	15/07/25	0,12	0,12	1-MO.	80,0	9,60	41	1,5	MEC.	
1	4	RB975033	2C	NC	01/04/23	15/07/25	0,69	0,69	1-MO.	80,0	55,20	41	1,5	MEC.	
1	5	RB975033	2C	NC	01/04/23	15/07/25	0,74	0,74	1-MO.	80,0	59,20	41	1,5	MEC.	
1	6	IACCTC07-7207	FORM	NC	07/03/25		8,30	0,00	.		0,00	41	1,5	N/D	
1	7	CTC9003BT	3C	NC	01/04/22	28/05/25	3,83	3,83	1-MO.	75,0	287,25	41	1,5	MEC.	
1	8	IACCTC07-7207	FORM	NC	07/03/25		3,04	0,00	.		0,00	41	1,5	N/D	
1	9	CTC9003BT	3C	NC	01/04/22	28/05/25	4,09	4,09	1-MO.	75,0	306,75	41	1,5	MEC.	
1	10	IACCTC07-8008	2C	NC	01/04/23	15/07/25	33,12	33,12	1-MO.	30,0	993,60	41	1,5	MEC.	
1	11	RB975033	2C	NC	01/04/23	15/07/25	14,41	14,41	1-MO.	100,0	1.441,00	41	1,5	MEC.	
1	12	RB975033	3C	NC	01/04/22	15/07/25	3,56	3,56	1-MO.	100,0	356,00	41	1,5	MEC.	
1	13	CTC9003BT	3C	NC	01/04/22	28/05/25	1,95	1,95	1-MO.	75,0	146,25	41	1,5	MEC.	
1	15	CTC9003BT	3C	NC	01/04/22	04/08/24	2,34	2,34	1-MO.	75,0	175,50	41	1,5	MEC.	
1	16	CTC9003BT	3C	NC	01/04/22	28/05/25	3,93	3,93	1-MO.	75,0	294,75	41	1,5	MEC.	
1	17	CTC9003BT	3C	NC	01/04/22	28/05/25	5,22	5,22	1-MO.	75,0	391,50	41	1,5	MEC.	
1	18	CTC2	5C	NC	01/04/20	15/07/25	30,43	30,43	1-MO.	75,0	2.282,25	41	1,5	MEC.	
1	19	CTC9003BT	3C	NC	01/04/22	28/05/25	4,26	4,26	1-MO.	75,0	319,50	41	1,5	MEC.	
1	20	CTC9003BT	3C	NC	01/04/22	28/05/25	4,34	4,34	1-MO.	75,0	325,50	41	1,5	MEC.	
1	21	CTC2	5C	NC	01/04/20	15/07/25	23,41	23,41	1-MO.	80,0	1.872,80	41	1,5	MEC.	
1	22	CTC9003BT	3C	NC	01/04/22	28/05/25	0,02	0,02	1-MO.	85,0	1,70	41	1,5	MEC.	
1	23	CTC9003BT	3C	NC	01/04/22	28/05/25	1,70	1,70	1-MO.	85,0	144,50	41	1,5	MEC.	
1	24	CTC9003BT	3C	NC	01/04/22	28/05/25	4,25	4,25	1-MO.	85,0	361,25	41	1,5	MEC.	
1	25	RB127825	FORM	NC	07/03/25		8,33	0,00	.		0,00	41	1,5	N/D	
1	27	CTC9003BT	3C	NC	01/04/22	28/05/25	1,46	1,46	1-MO.	80,0	116,80	41	1,5	MEC.	
1	28	CTC9001	3C	NC	01/04/22	28/05/25	8,92	8,92	1-MO.	90,0	802,80	41	1,5	MEC.	
1	29	CTC9001	3C	NC	01/04/22	28/05/25	2,52	2,52	1-MO.	90,0	226,80	41	1,5	MEC.	
1	30	CTC9001	3C	NC	01/04/22	28/05/25	2,50	2,50	1-MO.	90,0	225,00	41	1,5	MEC.	
1	31	CTC9001	3C	NC	01/04/22	28/05/25	24,13	24,13	1-MO.	85,0	2.051,05	41	1,5	MEC.	
1	32	CTC9001	3C	NC	01/04/22	28/05/25	23,26	23,26	1-MO.	85,0	1.977,10	41	1,5	MEC.	
Total/Média (3 / 527 · SANTA MARIA II)							236,48	216,81		74,9	16.247,45				

N: 7729790.75552365
E: 329893.95847101
LAT: −20°31'22.8592242" (−20.52301645116)
LONG: −46°37'53.2584759" (−46.63146068776)

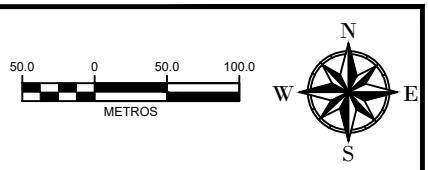

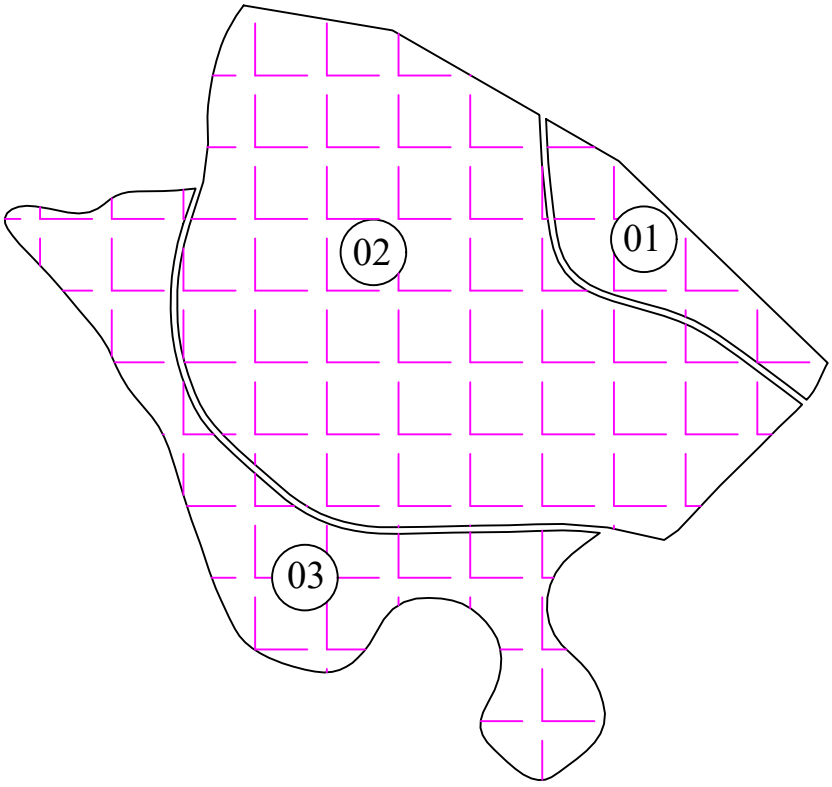

RB 96-6928

TABELA DE VARIEDADE	
VARIEDADE	ÁREA
RB966928	18,21
Total Geral	18,21

IPIRANGA AGROINDUSTRIAL

PROJETO: CADERNO DE MAPA 25'26	DATA: 31/07/2024	ESCALA: 1:5000	TOPÓGRAFO: CRISTIAN
FAZENDA: 533 - BELEZA I	MUNICÍPIO: DELFINOPOLIS		ÁREA (ha): 18,21
PROPRIETÁRIO: PAULO RODRIGUES	UNIDADE: PASSOS MG		

Caderno de Mapas

Bloco	Talhao	Variedade	Estágio de Corte	Amb. Prod.	Data Plantio	Último Corte	Área (ha)	Estimativas Área (ha)	Finalid	Produt.	Prod. Total	Dist.	Esp.	Tipo Corte	Experimento
3 · REG 3			**533 · ST ALTO BELEZAS**				**PAULO DE ARAUJO RODRIGUES E OUTROS**								
1	1	RB966928	1C	NC	18/04/24		1,51	1,51	1-MO.	130,0	196,30	31	1,5	MEC.	
1	2	RB966928	1C	NC	19/04/24	05/05/25	11,98	11,98	1-MO.	130,0	1.557,40	31	1,5	MEC.	
1	3	RB966928	1C	NC	19/04/24	05/05/25	4,72	4,72	1-MO.	130,0	613,60	31	1,5	MEC.	
Total/Média (3 / 533 · ST ALTO BELEZAS)							18,21	18,21		130,0	2.367,30				

N: 7729365.12998022
E: 329839.08643202
LAT: −20°31'36.6814144" (−20.52685594845)
LONG: −46°37'55.2992277" (−46.63202756325)

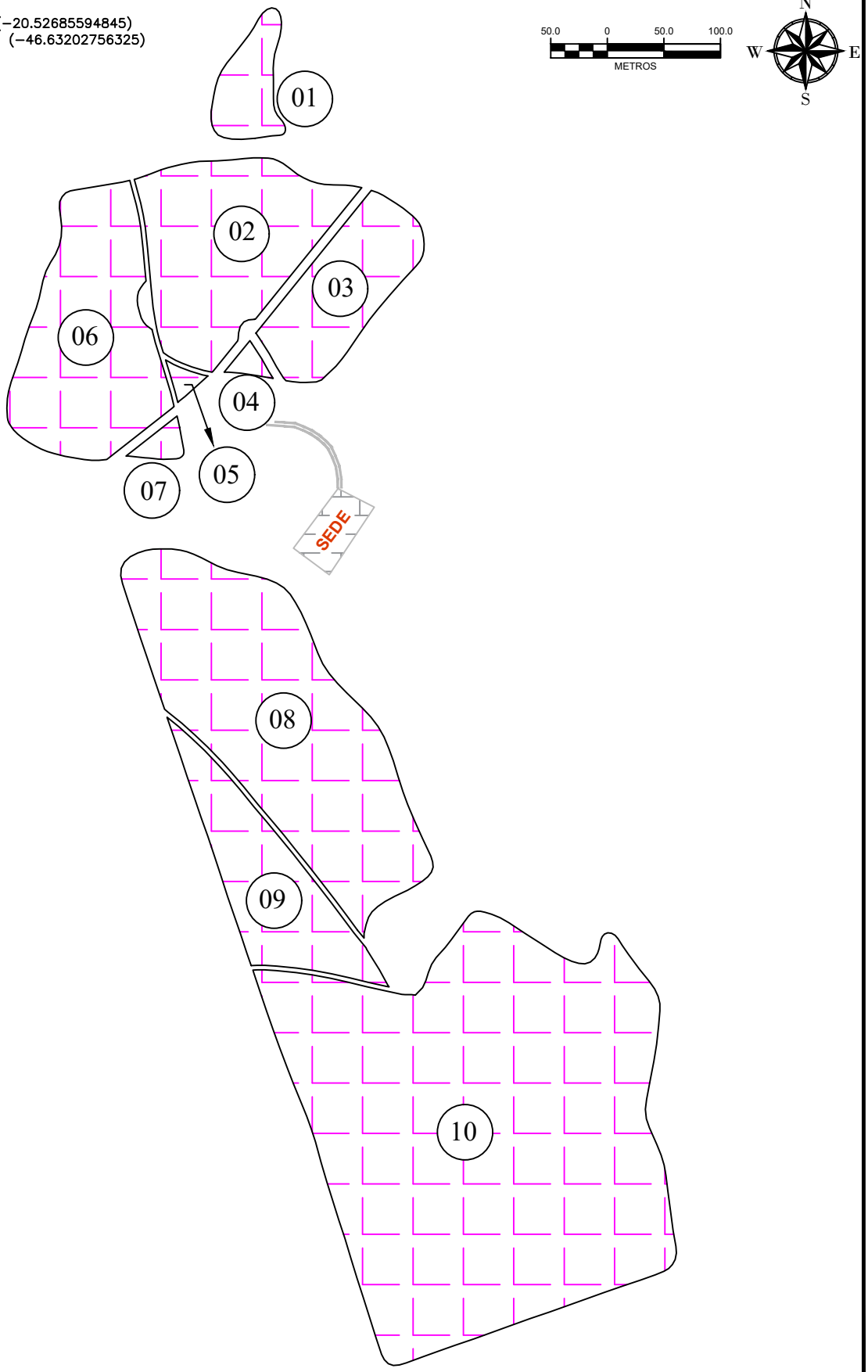

RB 96-6928

TABELA DE VARIEDADE	
VARIEDADE	ÁREA
RB966928	33,49
Total Geral	33,49

IPIRANGA AGROINDUSTRIAL

PROJETO: CADERNO DE MAPA 25'26	DATA: 20-08-2024	ESCALA: 1:5000	TOPÓGRAFO: LUIS DUARTE
FAZENDA: 534 - BELEZA II	MUNICÍPIO: DELFINOPOLIS MG		ÁREA (ha): 33,49
PROPRIETÁRIO: PAULO RODRIGUES	UNIDADE: PASSOS MG		

Caderno de Mapas

Bloco	Talhao	Variedade	Estágio de Corte	Amb. Prod.	Data Plantio	Último Corte	Área (ha)	Estimativas Área (ha)	Finalid	Produt.	Prod. Total	Dist.	Esp.	Tipo Corte	Experimento
3 · REG 3			**534 · SERRINHA/BLZ II**				**PAULO DE ARAUJO RODRIGUES E OUTROS**								
1	1	RB966928	1C	NC	22/04/24	05/05/25	0,73	0,73	1-MO.	130,0	94,90	33	1,5	MEC.	
1	2	RB966928	1C	NC	20/04/24	05/05/25	3,39	3,39	1-MO.	130,0	440,70	33	1,5	MEC.	
1	3	RB966928	1C	NC	22/04/24	05/05/25	3,60	3,60	1-MO.	130,0	468,00	33	1,5	MEC.	
1	4	RB966928	1C	NC	22/04/24	05/05/25	0,08	0,08	1-MO.	130,0	10,40	33	1,5	MEC.	
1	5	RB966928	1C	NC	22/04/24	05/05/25	0,15	0,15	1-MO.	130,0	19,50	33	1,5	MEC.	
1	6	RB966928	1C	NC	20/04/24	05/05/25	0,09	0,09	1-MO.	130,0	11,70	33	1,5	MEC.	
1	7	RB966928	1C	NC	20/04/24	05/05/25	1,87	1,87	1-MO.	130,0	243,10	33	1,5	MEC.	
1	8	RB966928	1C	NC	26/04/24	05/05/25	6,44	6,44	1-MO.	130,0	837,20	33	1,5	MEC.	
1	9	RB966928	1C	NC	24/04/24	05/05/25	2,20	2,20	1-MO.	130,0	286,00	33	1,5	MEC.	
1	10	RB966928	1C	NC	24/04/24	05/05/25	14,94	14,94	1-MO.	130,0	1.942,20	33	1,5	MEC.	
Total/Média (3 / 534 · SERRINHA/BLZ II)							33,49	33,49		130,0	4.353,70				

N: 7729790.75552365
E: 329893.95847101
LAT: −20°31'22.8592242" (−20.52301645116)
LONG: −46°37'53.2584759" (−46.63146068776)

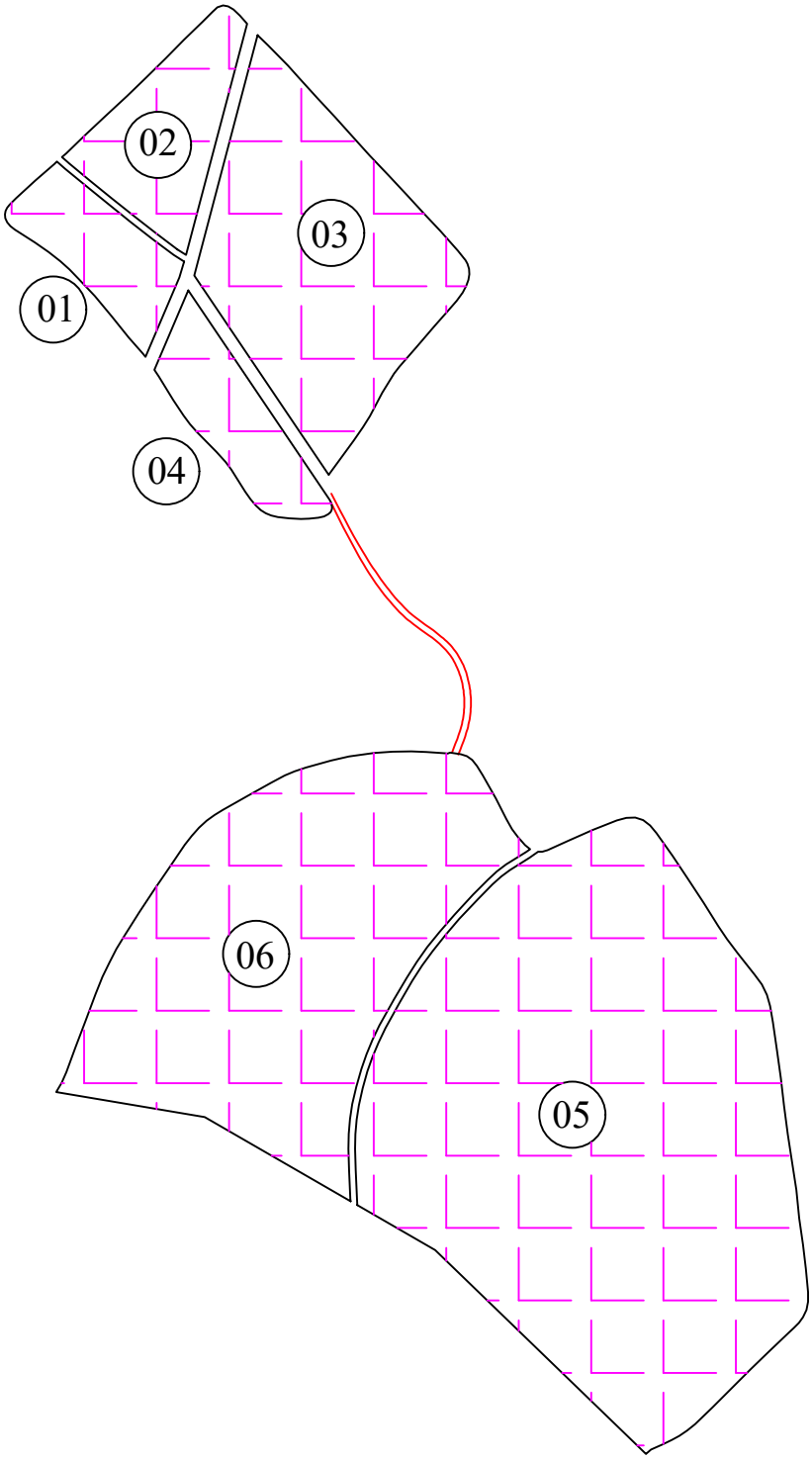

RB 96-6928

TABELA DE VARIEDADE	
VARIEDADE	ÁREA
RB966928	23,65
Total Geral	23,65

IPIRANGA AGROINDUSTRIAL

PROJETO: CADERNO DE MAPA 25'26	DATA: 31/07/2024	ESCALA: 1:5000	TOPÓGRAFO: CRISTIAN
FAZENDA: 535 - PORTO DA PEDRA	MUNICÍPIO: DELFINOPOLIS		ÁREA (ha): 23,65
PROPRIETÁRIO: PAULO RODRIGUES	UNIDADE: PASSOS MG		

Caderno de Mapas

Bloco	Talhao	Variedade	Estágio de Corte	Amb. Prod.	Data Plantio	Último Corte	Área (ha)	Estimativas Área (ha)	Finalid	Produt.	Prod. Total	Dist.	Esp.	Tipo Corte	Experimento
3 · REG 3			**535 · SER/FLAMB_P PED**				**PAULO DE ARAUJO RODRIGUES E OUTROS**								
1	1	RB966928	1C	NC	27/04/24	05/05/25	1,20	1,20	1-MO.	130,0	156,00	32	1,5	MEC.	
1	2	RB966928	1C	NC	27/04/24	05/05/25	3,54	3,54	1-MO.	130,0	460,20	32	1,5	MEC.	
1	3	RB966928	1C	NC	27/04/24	05/05/25	0,84	0,84	1-MO.	130,0	109,20	32	1,5	MEC.	
1	4	RB966928	1C	NC	27/04/24	05/05/25	0,89	0,89	1-MO.	130,0	115,70	32	1,5	MEC.	
1	5	RB966928	1C	NC	27/04/24		6,34	6,34	1-MO.	130,0	824,20	32	1,5	MEC.	
1	6	RB966928	1C	NC	27/04/24		10,84	10,84	1-MO.	130,0	1.409,20	32	1,5	MEC.	
Total/Média (3 / 535 · SER/FLAMB_P PED)							23,65	23,65		130,0	3.074,50				

N: 7733859.30224778
E: 331039.97033129
LAT: -20°29'12.3683678" (-20.48676899107)
LONG: -46°37'13.6928831" (-46.62047024531)

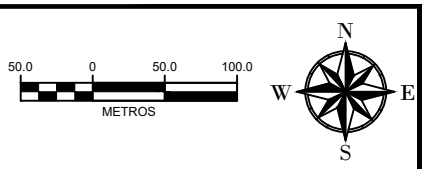

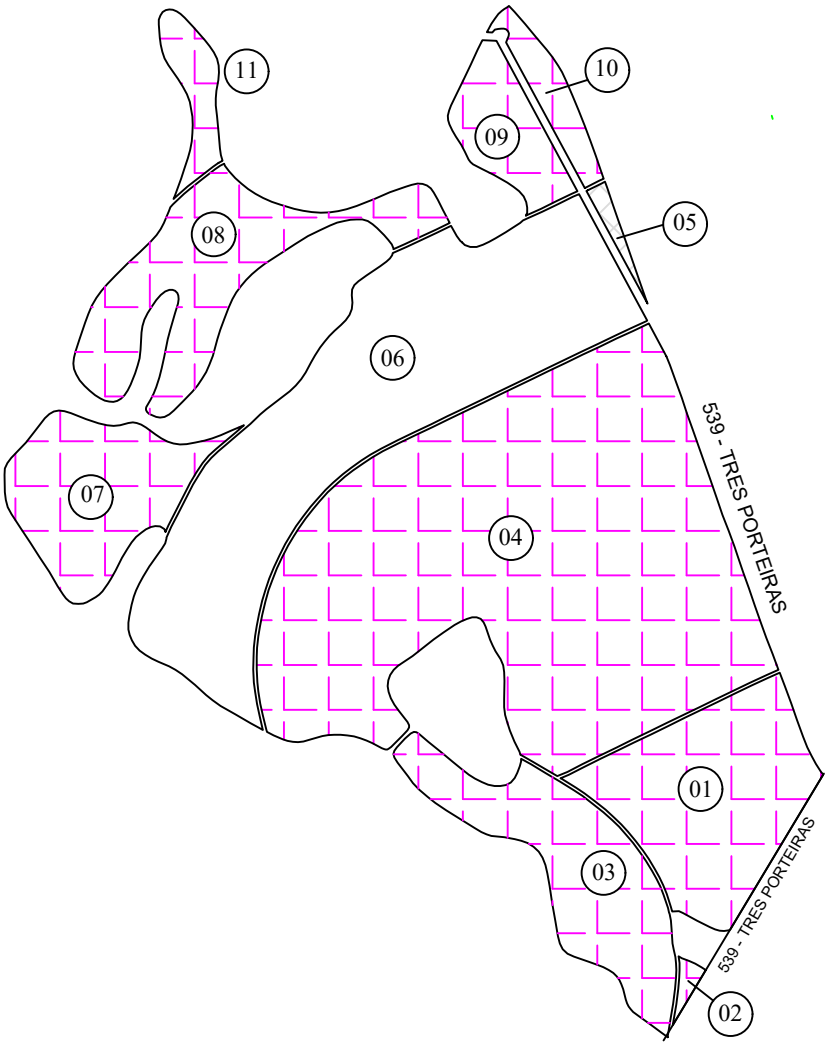

CTC - 4
A DEFINIR
RB 96-6928

TABELA DE VARIEDADE	
VARIEDADE	ÁREA
CTC4	6,47
RB966928	48,25
Total Geral	54,72

IPIRANGA AGROINDUSTRIAL

PROJETO: CADERNO DE MAPA 25´26	DATA: 21/10/2025	ESCALA: 1:5000	TOPÓGRAFO: LUIS DUARTE
FAZENDA: 538 - PONTE ALTA	MUNICÍPIO: PASSOS - MG		ÁREA (ha): 54,72
PROPRIETÁRIO: PAULO RODRIGUES	UNIDADE: IPIRANGA PASSOS S.A.		

Caderno de Mapas

Bloco	Talhao	Variedade	Estágio de Corte	Amb. Prod.	Data Plantio	Último Corte	Área (ha)	Estimativas Área (ha)	Finalid	Produt.	Prod. Total	Dist.	Esp.	Tipo Corte	Experimento
3 · REG 3			**538 · SANTOS REIS**				**PAULO DE ARAUJO RODRIGUES E OUTROS**								
1	1	RB966928	2C	NC	01/04/23	12/05/25	5,16	5,16	1-MO.	120,0	619,20	36	1,5	MEC.	
1	2	RB966928	2C	NC	01/04/23	12/05/25	0,13	0,13	1-MO.	120,0	15,60	36	1,5	MEC.	
1	3	RB966928	2C	NC	01/04/23	12/05/25	4,20	4,20	1-MO.	120,0	504,00	36	1,5	MEC.	
1	4	RB966928	2C	NC	01/04/23	12/05/25	21,13	21,13	1-MO.	120,0	2.535,60	36	1,5	MEC.	
1	5	CTC4	2C	NC	01/04/23	12/05/25	0,19	0,19	1-MO.	120,0	22,80	36	1,5	MEC.	
1	6	CTC4	2C	NC	01/04/23	12/05/25	6,28	6,28	1-MO.	120,0	753,60	36	1,5	MEC.	
1	6	RB966928	2C	NC	01/04/23	12/05/25	6,17	6,17	1-MO.	120,0	740,40	36	1,5	MEC.	
1	7	RB966928	2C	NC	01/04/23	12/05/25	3,57	3,57	1-MO.	120,0	428,40	36	1,5	MEC.	
1	8	RB966928	2C	NC	01/04/23	12/05/25	4,54	4,54	1-MO.	120,0	544,80	36	1,5	MEC.	
1	9	RB966928	2C	NC	01/04/23	12/05/25	1,65	1,65	1-MO.	120,0	198,00	36	1,5	MEC.	
1	10	RB966928	2C	NC	01/04/23	12/05/25	0,84	0,84	1-MO.	120,0	100,80	36	1,5	MEC.	
1	11	RB966928	2C	NC	01/04/23	12/05/25	0,86	0,86	1-MO.	120,0	103,20	36	1,5	MEC.	
Total/Média (3 / 538 · SANTOS REIS)							54,72	54,72		120,0	6.566,40				

N: 7733958.46620610
E: 331559.36652093
LAT: -20°29'9.3107912" (-20.48591966422)
LONG: -46°36'55.7354498" (-46.61548206939)

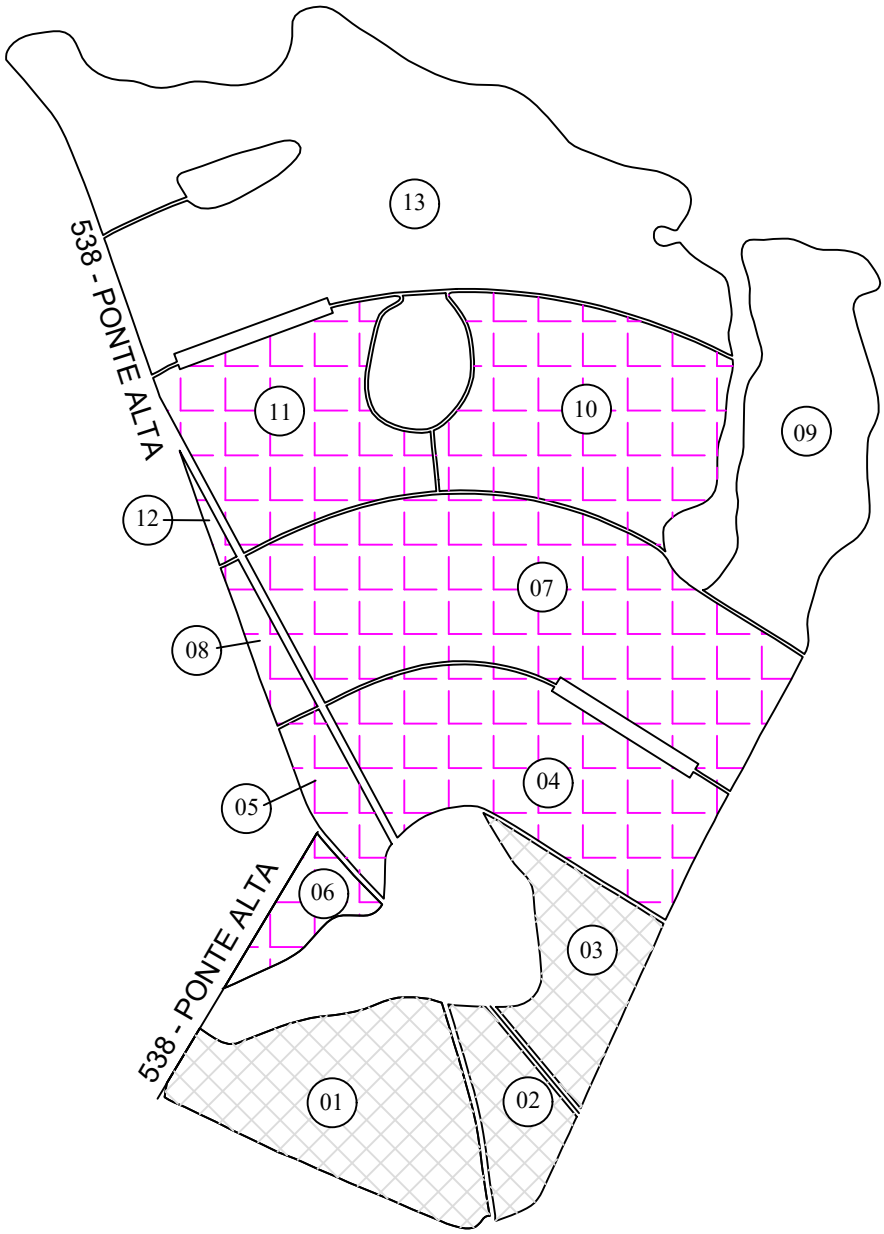

CTC - 4
RB 96-6928
A DEFINIR

TABELA DE VARIEDADE	
VARIEDADE	ÁREA
CTC4	23,66
RB966928	53,58
Total Geral	77,24

IPIRANGA AGROINDUSTRIAL

PROJETO: CADERNO DE MAPA 25´26	DATA: 21/10/2025	ESCALA: 1:5000	TOPÓGRAFO: CRISTIAN
FAZENDA: 539 - TRES PORTEIRAS	MUNICÍPIO: PASSOS - MG		ÁREA (ha): 77,24
PROPRIETÁRIO: PAULO RODRIGUES	UNIDADE: IPIRANGA PASSOS S.A.		

Caderno de Mapas

Bloco	Talhao	Variedade	Estágio de Corte	Amb. Prod.	Data Plantio	Último Corte	Área (ha)	Estimativas Área (ha)	Finalid	Produt.	Prod. Total	Dist.	Esp.	Tipo Corte	Experimento
3 · REG 3			**539 · TRES PORTEIRAS**				**PAULO DE ARAUJO RODRIGUES E OUTROS**								
1	1	CTC4	2C	NC	01/04/23	12/05/25	6,71	6,71	1-MO.	120,0	805,20	36	1,5	MEC.	
1	2	CTC4	2C	NC	01/04/23	12/05/25	2,06	2,06	1-MO.	120,0	247,20	36	1,5	MEC.	
1	3	CTC4	2C	NC	01/04/23	12/05/25	3,32	3,32	1-MO.	120,0	398,40	36	1,5	MEC.	
1	4	RB966928	2C	NC	01/04/23	12/05/25	7,82	7,82	1-MO.	120,0	938,40	36	1,5	MEC.	
1	5	RB966928	2C	NC	01/04/23	12/05/25	1,32	1,32	1-MO.	120,0	158,40	36	1,5	MEC.	
1	6	RB966928	2C	NC	01/04/24	12/05/25	1,23	1,23	1-MO.	120,0	147,60	36	1,5	MEC.	
1	7	RB966928	2C	NC	01/04/24	12/05/25	12,84	12,84	1-MO.	120,0	1.540,80	36	1,5	MEC.	
1	8	RB966928	2C	NC	01/04/23	12/05/25	0,80	0,80	1-MO.	120,0	96,00	36	1,5	MEC.	
1	9	CTC4	2C	NC	01/04/23	12/05/25	1,34	1,34	1-MO.	120,0	160,80	36	1,5	MEC.	
1	9	RB966928	2C	NC	01/04/23	12/05/25	5,39	5,39	1-MO.	120,0	646,80	36	1,5	MEC.	
1	10	RB966928	2C	NC	01/04/23	12/05/25	7,89	7,89	1-MO.	120,0	946,80	36	1,5	MEC.	
1	11	RB966928	2C	NC	01/04/23	12/05/25	6,00	6,00	1-MO.	120,0	720,00	36	1,5	MEC.	
1	12	RB966928	2C	NC	01/04/23	12/05/25	0,17	0,17	1-MO.	120,0	20,40	36	1,5	MEC.	
1	13	CTC4	2C	NC	01/04/23	12/05/25	10,23	10,23	1-MO.	120,0	1.227,60	36	1,5	MEC.	
1	13	RB966928	2C	NC	01/04/23	12/05/25	10,12	10,12	1-MO.	120,0	1.214,40	36	1,5	MEC.	
Total/Média (3 / 539 · TRES PORTEIRAS)							77,24	77,24		120,0	9.268,80				

N: 7735423.91238031
E: 327631.31296950
LAT: −20°28'18.9484012" (−20.47193011144)
LONG: −46°39'9.3923029" (−46.65260897302)

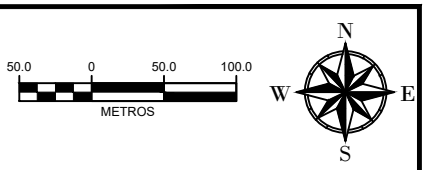

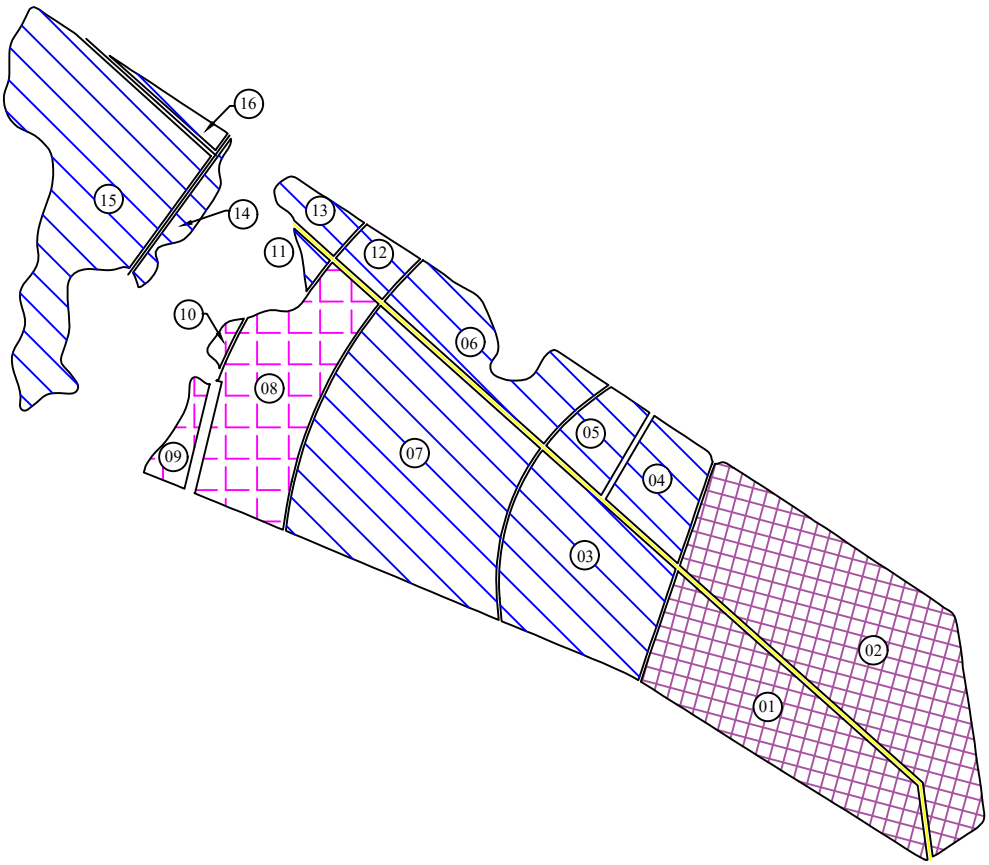

RB 85-5156
RB 96-6928
IAC CTC 07-8008

TABELA DE VARIEDADE

VARIEDADE	ÁREA
IACCTC07-8008	22,89
RB855156	44,05
RB966928	8,05
Total Geral	**74,99**

IPIRANGA AGROINDUSTRIAL

PROJETO: CADERNO DE MAPA 25'26	DATA: 21/10/2025	ESCALA: 1:5000	TOPÓGRAFO: CRISTIAN
FAZENDA: 540 - SANTA MARIA (NOVO HORIZONTE)	MUNICÍPIO: DELFINOPOLIS MG		ÁREA (ha): 74,99
PROPRIETÁRIO: PAULO RODRIGUES	UNIDADE: PASSOS MG		

Caderno de Mapas

Bloco	Talhao	Variedade	Estágio de Corte	Amb. Prod.	Data Plantio	Data Último Corte	Área (ha)	Estimativas Área (ha)	Estimativas Finalid	Estimativas Produt.	Prod. Total	Dist.	Esp.	Tipo Corte	Experimento
3 · REG 3			**540 · NOVO HORIZONTE**				**PAULO DE ARAUJO RODRIGUES E OUTROS**								
1	1	IACCTC07-8008	2C	NC	01/04/23	06/11/25	8,32	8,32	1-MO.	105,0	873,60	39	1,5	MEC.	
1	2	IACCTC07-8008	2C	NC	01/04/23	06/11/25	14,57	14,57	1-MO.	105,0	1.529,85	39	1,5	MEC.	
1	3	RB855156	2C	NC	01/04/23	16/04/25	7,43	7,43	1-MO.	110,0	817,30	39	1,5	MEC.	
1	4	RB855156	2C	NC	01/04/23	16/04/25	2,59	2,59	1-MO.	110,0	284,90	39	1,5	MEC.	
1	5	RB855156	2C	NC	01/04/23	16/04/25	1,72	1,72	1-MO.	110,0	189,20	39	1,5	MEC.	
1	6	RB855156	2C	NC	01/04/23	24/04/25	3,83	3,83	1-MO.	110,0	421,30	39	1,5	MEC.	
1	7	RB855156	2C	NC	01/04/23	24/04/25	13,90	13,90	1-MO.	110,0	1.529,00	39	1,5	MEC.	
1	8	RB966928	2C	NC	01/04/23	24/04/25	6,96	6,96	1-MO.	110,0	765,60	39	1,5	MEC.	
1	9	RB966928	2C	NC	01/04/23	24/04/25	0,87	0,87	1-MO.	110,0	95,70	39	1,5	MEC.	
1	10	RB966928	2C	NC	01/04/23	24/04/25	0,22	0,22	1-MO.	110,0	24,20	39	1,5	MEC.	
1	11	RB855156	2C	NC	01/04/23	24/04/25	0,26	0,26	1-MO.	110,0	28,60	39	1,5	MEC.	
1	12	RB855156	2C	NC	01/04/23	24/04/25	0,96	0,96	1-MO.	110,0	105,60	39	1,5	MEC.	
1	13	RB855156	2C	NC	01/04/23	24/04/25	1,00	1,00	1-MO.	110,0	110,00	39	1,5	MEC.	
1	14	RB855156	2C	NC	01/04/23	24/04/25	0,79	0,79	1-MO.	110,0	86,90	39	1,5	MEC.	
1	15	RB855156	2C	NC	01/04/23	24/04/25	0,44	0,44	1-MO.	110,0	48,40	39	1,5	MEC.	
1	16	RB855156	2C	NC	01/04/23	24/04/25	10,98	10,98	1-MO.	110,0	1.207,80	39	1,5	MEC.	
1	17	RB855156	2C	NC	01/04/23	24/04/25	0,15	0,15	1-MO.	110,0	16,50	39	1,5	MEC.	
Total/Média (3 / 540 · NOVO HORIZONTE)							74,99	74,99		108,5	8.134,45				

N: 7713853.634
E: 335030.8915
LAT: −20°40'4.1716" (−20.66782545)
LONG: −46°35'2.6806" (−46.58407794)

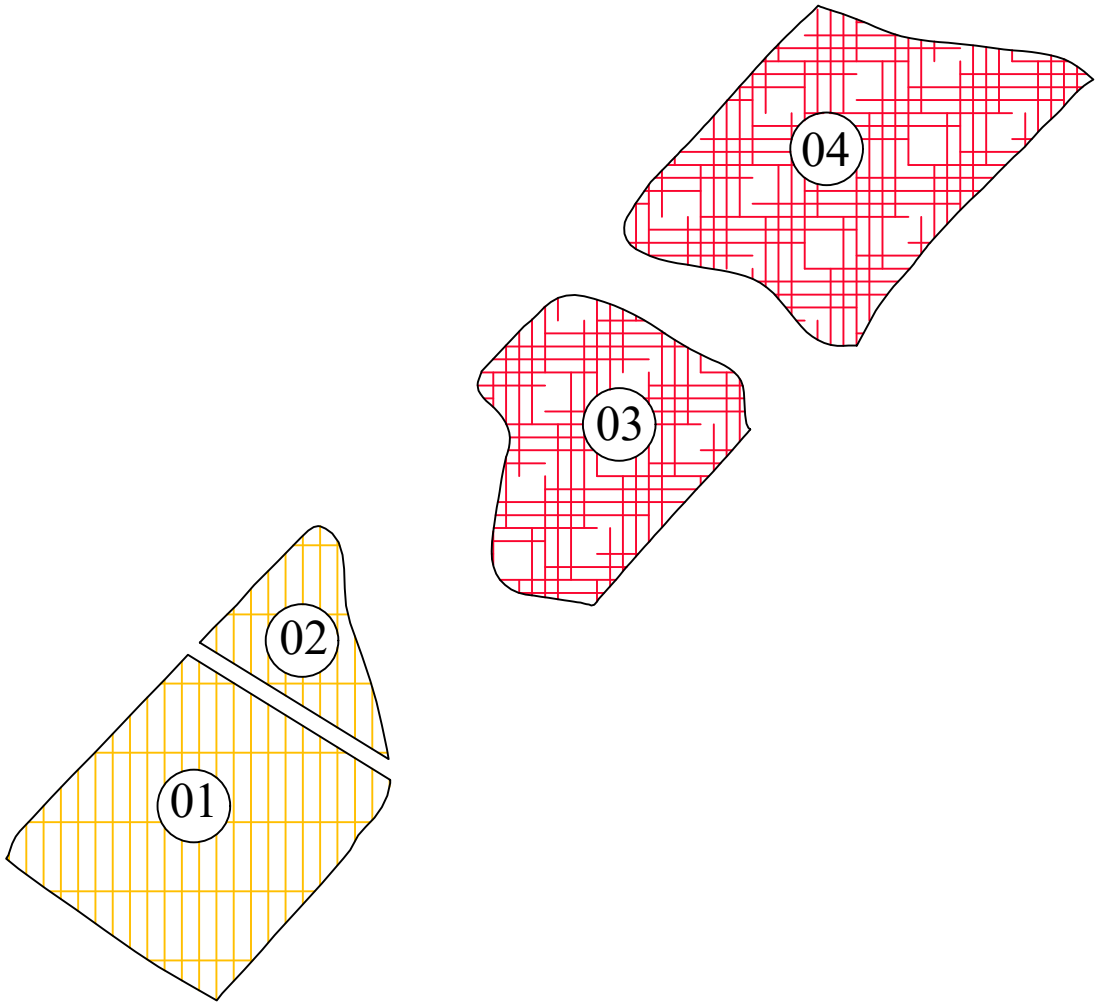

RB 98-5476
IAC SP 01-5503

TABELA DE VARIEDADE	
VARIEDADE	ÁREA
RB985476	3,28
IAC SP 01-5503	4,95
Total Geral	**8,23**

IPIRANGA AGROINDUSTRIAL

PROJETO: CADERNO DE MAPA 25'26	DATA: 16/06/2025	ESCALA: 1:5000	TOPÓGRAFO: CRISTIAN
FAZENDA: 543 - SITIO SAO SEBASTIAO (INDAIA I)	MUNICÍPIO: DELFINOPOLIS - MG		ÁREA (ha): 8,23
PROPRIETÁRIO: PAULO RODRIGUES	UNIDADE: IPIRANGA PASSOS S.A.		

Caderno de Mapas

Bloco	Talhao	Variedade	Estágio de Corte	Amb. Prod.	Data Plantio	Último Corte	Área (ha)	Estimativas Área (ha)	Finalid	Produt.	Prod. Total	Dist.	Esp.	Tipo Corte	Experimento
3 · REG 3			**543 · INDAIA I**				**PAULO DE ARAUJO RODRIGUES E OUTROS**								
1	1	RB985476	1C	NC	30/04/24	07/07/25	2,57	2,57	1-MO.	120,0	308,40	51	1,5	MEC.	
1	2	RB985476	1C	NC	30/04/24	07/07/25	0,71	0,71	1-MO.	120,0	85,20	51	1,5	MEC.	
1	3	RB985476	1C	NC	03/04/24		1,98	0,00	.		0,00	51	1,5	N/D	
1	4	RB985476	1C	NC	01/04/24	07/08/25	2,96	2,96	5-OU.	50,0	148,00	51	1,5	MEC.	
Total/Média (3 / 543 · INDAIA I)							8,22	6,24		86,8	541,60				

N: 7741477.53143141
E: 316213.36778376
LAT: −20°24'58.2447324" (−20.41617909234)
LONG: −46°45'41.1092269" (−46.76141922970)

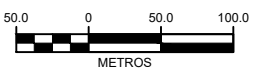



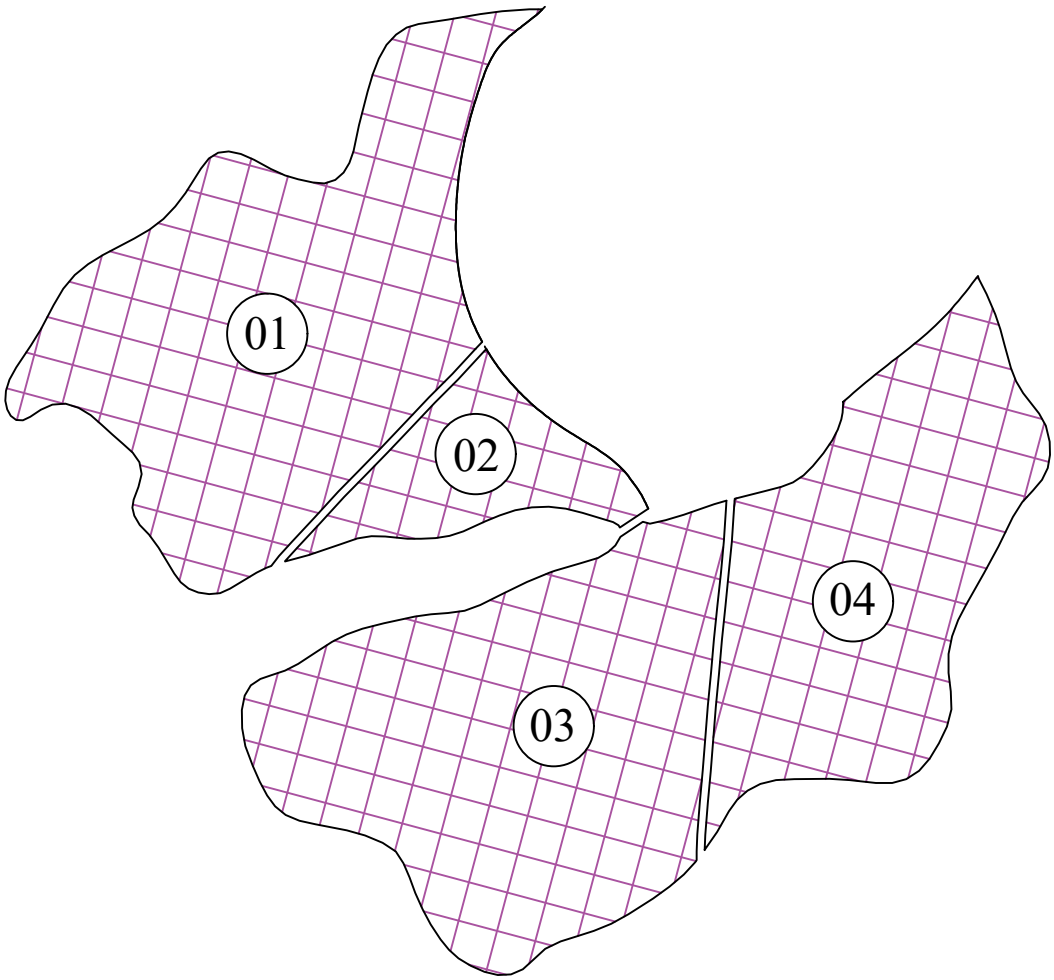

IAC CTC 07-8008

TABELA DE VARIEDADE	
VARIEDADE	ÁREA
IACCTC07-8008	16,24
Total Geral	16,24

IPIRANGA AGROINDUSTRIAL

PROJETO: CADERNO DE MAPA 25'26	DATA: 23/10/2025	ESCALA: 1:5000	TOPÓGRAFO: CRISTIAN
FAZENDA: 545 - NOVA BARRA I	MUNICÍPIO: DELFINOPOLIS MG		ÁREA (ha): 16,24
PROPRIETÁRIO: PAULO RODRIGUES	UNIDADE: IPIRANGA PASSOS		

Caderno de Mapas

Bloco	Talhao	Variedade	Estágio de Corte	Amb. Prod.	Data Plantio	Último Corte	Área (ha)	Estimativas Área (ha)	Finalid	Produt.	Prod. Total	Dist.	Esp.	Tipo Corte	Experimento
3 · REG 3			**545 · NOVA BARRA I**				**PAULO DE ARAUJO RODRIGUES E OUTROS**								
1	1	IACCTC07-8008	1C	NC	13/04/24		5,60	5,60	1-MO.	120,0	672,00	52	1,5	MEC.	
1	2	IACCTC07-8008	1C	NC	13/04/24		1,22	1,22	1-MO.	120,0	146,40	52	1,5	MEC.	
1	3	IACCTC07-8008	1C	NC	14/04/24	17/09/25	5,42	5,42	1-MO.	120,0	650,40	52	1,5	MEC.	
1	4	IACCTC07-8008	1C	NC	14/04/24		4,03	4,03	1-MO.	120,0	483,60	52	1,5	MEC.	
Total/Média (3 / 545 · NOVA BARRA I)							16,27	16,27		120,0	1.952,40				

N: 7713853.634
E: 335030.8915
LAT: −20°40'4.1716" (−20.66782545)
LONG: −46°35'2.6806" (−46.58407794)

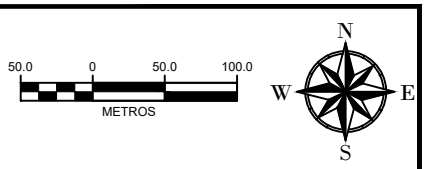

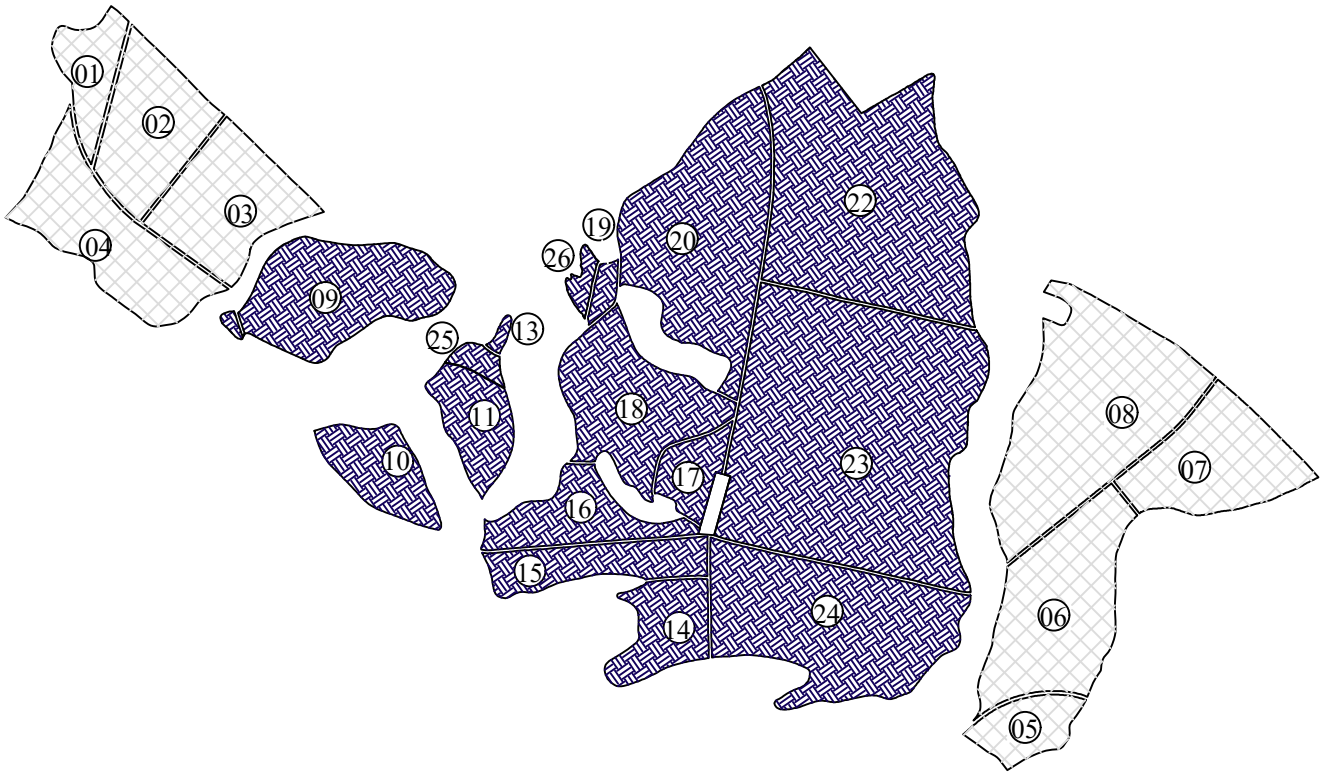

CTC - 4

CTC - 9006

TABELA DE VARIEDADE	
VARIEDADE	ÁREA
A DEFINIR	0,62
CTC4	31,68
CTC9006	61,89
Total Geral	**94,19**

IPIRANGA AGROINDUSTRIAL

PROJETO: CADERNO DE MAPA 25'26	DATA: 06/05/2024	ESCALA: 1:5000	TOPÓGRAFO: LUIS DUARTE
FAZENDA: 548 - ATÉ VER	MUNICÍPIO: PASSOS - MG		ÁREA (ha): 94,19
PROPRIETÁRIO:	UNIDADE: IPIRANGA PASSOS S.A.		

Caderno de Mapas

Bloco	Talhao	Variedade	Estágio de Corte	Amb. Prod.	Data Plantio	Último Corte	Área (ha)	Estimativas Área (ha)	Finalid	Produt.	Prod. Total	Dist.	Esp.	Tipo Corte	Experimento
3 · REG 3			**548 · ATE VER**				**LUIZ FLAVIO LEMOS**								
1	1	CTC4	2C	NC	24/09/22	16/06/25	1,52	1,52	1-MO.	103,0	156,56	39	1,5	MEC.	
1	2	CTC4	2C	NC	24/09/22	16/06/25	3,46	3,46	1-MO.	103,0	356,38	39	1,5	MEC.	
1	3	CTC4	2C	NC	24/09/22	16/06/25	3,76	3,76	1-MO.	103,0	387,28	39	1,5	MEC.	
1	4	CTC4	2C	NC	24/09/22	16/06/25	4,24	4,24	1-MO.	103,0	436,72	39	1,5	MEC.	
1	5	CTC4	2C	NC	21/09/22	16/06/25	1,40	1,40	1-MO.	103,0	144,20	39	1,5	MEC.	
1	6	CTC4	2C	NC	21/09/22	16/06/25	5,36	5,36	1-MO.	103,0	552,08	39	1,5	MEC.	
1	7	CTC4	2C	NC	21/09/22	16/06/25	3,87	3,87	1-MO.	103,0	398,61	39	1,5	MEC.	
1	8	CTC4	2C	NC	22/09/22	16/06/25	8,07	8,07	1-MO.	103,0	831,21	39	1,5	MEC.	
1	9	CTC9006	FORM	NC	13/12/24		4,67	0,00	.		0,00	39	1,5	N/D	
1	10	CTC9006	FORM	NC	07/02/25		1,95	0,00	.		0,00	39	1,5	N/D	
1	11	CTC9006	FORM	NC	13/01/25		1,79	0,00	.		0,00	39	1,5	N/D	
1	13	CTC9006	FORM	NC	13/01/25		0,11	0,00	.		0,00	39	1,5	N/D	
1	14	CTC9006	FORM	NC	12/12/24		1,92	0,00	.		0,00	39	1,5	N/D	
1	15	CTC9006	FORM	NC	13/01/25		2,11	0,00	.		0,00	39	1,5	N/D	
1	16	CTC9006	FORM	NC	13/01/25		2,22	0,00	.		0,00	39	1,5	N/D	
1	17	CTC9006	FORM	NC	13/01/25		1,10	0,00	.		0,00	39	1,5	N/D	
1	18	CTC9006	FORM	NC	13/01/25		4,27	0,00	.		0,00	39	1,5	N/D	
1	19	CTC9006	FORM	NC	13/01/25		0,29	0,00	.		0,00	39	1,5	N/D	
1	21	CTC9006	FORM	NC	15/01/25		7,23	0,00	.		0,00	39	1,5	N/D	
1	22	CTC9006	FORM	NC	18/01/25		10,98	0,00	.		0,00	39	1,5	N/D	
1	23	CTC9006	FORM	NC	20/01/25		15,87	0,00	.		0,00	39	1,5	N/D	
1	24	CTC9006	FORM	NC	12/12/24		7,38	0,00	.		0,00	39	1,5	N/D	
1	25	A DEFINIR	EXP	IN	01/01/25		0,33	0,00	.		0,00	27	1,5	N/D	
1	26	A DEFINIR	EXP	IN	01/01/25		0,29	0,00	.		0,00	27	1,5	N/D	
Total/Média (3 / 548 · ATE VER)							94,19	31,68		103,0	3.263,04				

N: 7713853.634
E: 335030.8915
LAT: −20°40'4.1716" (−20.66782545)
LONG: −46°35'2.6806" (−46.58407794)

50.0 0 50.0 100.0
METROS

N
W E
S

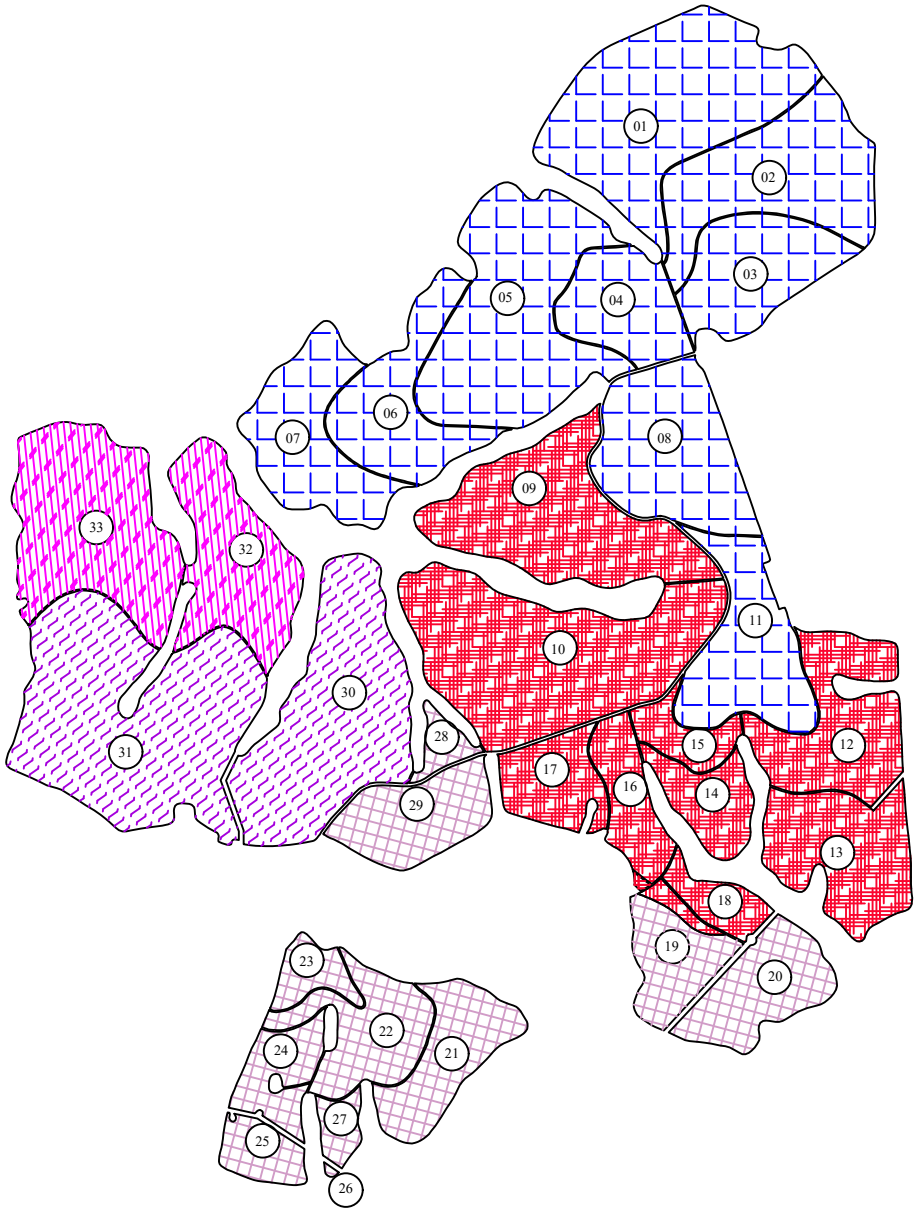

CTC - 2
CTC - 9007
CTC -2994
IAC CTC 07-7207
IAC SP 01-5503

TABELA DE VARIEDADE

VARIEDADE	ÁREA
CTC2	76,16
CTC2994	18,31
CTC9007	30,59
IACCTC07-7207	31,15
IACSP01-5503	53,78
Total Geral	**209,99**

IPIRANGA AGROINDUSTRIAL

PROJETO	DATA	ESCALA	TOPÓGRAFO
CADERNO DE MAPA 25'26	06/05/2024	1:5000	LUIS DUARTE
FAZENDA	**MUNICÍPIO**		**ÁREA (ha)**
550 - ROSA MISTICA	PASSOS - MG		209,99
PROPRIETÁRIO	**UNIDADE**		
JOSÉ IVALDO RODRIGUES NETO E OUTS	IPIRANGA PASSOS S.A.		

Caderno de Mapas

Bloco	Talhao	Variedade	Estágio de Corte	Amb. Prod.	Data Plantio	Data Último Corte	Área (ha)	Estimativas Área (ha)	Estimativas Finalid	Estimativas Produt.	Prod. Total	Dist.	Esp.	Tipo Corte	Experimento
3 · REG 3			**550 · ROSA MISTICA**				**JOSE IVALDO RODRIGUES NETO E OUTRO(S)**								
1	1	CTC2	1C	NC	25/02/24	30/05/25	14,26	14,26	1-MO.	115,0	1.639,90	31	1,5	MEC.	
1	2	CTC2	1C	NC	25/02/24	30/05/25	9,30	9,30	1-MO.	115,0	1.069,50	31	1,5	MEC.	
1	3	CTC2	1C	NC	23/02/24	30/05/25	6,04	6,04	1-MO.	115,0	694,60	31	1,5	MEC.	
1	4	CTC2	1C	NC	26/02/24	30/05/25	4,81	4,81	1-MO.	115,0	553,15	31	1,5	MEC.	
1	5	CTC2	1C	NC	25/02/24	30/05/25	13,12	13,12	1-MO.	115,0	1.508,80	31	1,5	MEC.	
1	6	CTC2	1C	NC	25/02/24	30/05/25	6,29	6,29	1-MO.	115,0	723,35	31	1,5	MEC.	
1	7	CTC2	1C	NC	27/02/24	30/05/25	6,86	6,86	1-MO.	115,0	788,90	31	1,5	MEC.	
1	8	CTC2	1C	NC	27/02/24	30/05/25	8,52	8,52	1-MO.	115,0	979,80	31	1,5	MEC.	
1	9	IACSP01-5503	1C	NC	29/02/24	30/05/25	10,99	10,99	1-MO.	115,0	1.263,85	31	1,5	MEC.	
1	10	IACSP01-5503	1C	NC	28/02/24	30/05/25	15,21	15,21	1-MO.	115,0	1.749,15	31	1,5	MEC.	
1	11	CTC2	1C	NC	27/02/24	30/05/25	6,96	6,96	1-MO.	115,0	800,40	31	1,5	MEC.	
1	12	IACSP01-5503	1C	NC	03/03/24	30/05/25	7,03	7,03	1-MO.	115,0	808,45	31	1,5	MEC.	
1	13	IACSP01-5503	1C	NC	04/03/24	30/05/25	6,81	6,81	1-MO.	115,0	783,15	31	1,5	MEC.	
1	14	IACSP01-5503	1C	NC	04/03/24	30/05/25	2,93	2,93	1-MO.	115,0	336,95	31	1,5	MEC.	
1	15	IACSP01-5503	1C	NC	07/03/24	30/05/25	1,90	1,90	1-MO.	115,0	218,50	31	1,5	MEC.	
1	16	IACSP01-5503	1C	NC	20/03/24	30/05/25	3,20	3,20	1-MO.	115,0	368,00	31	1,5	MEC.	
1	17	IACSP01-5503	1C	NC	13/03/24	30/05/25	3,46	3,46	1-MO.	115,0	397,90	31	1,5	MEC.	
1	18	IACSP01-5503	1C	NC	03/04/24	30/05/25	1,76	1,76	1-MO.	115,0	202,40	31	1,5	MEC.	
1	19	IACCTC07-7207	1C	NC	03/04/24	30/05/25	3,51	3,51	1-MO.	115,0	403,65	31	1,5	MEC.	
1	19	IACSP01-5503	1C	NC	03/04/24	30/05/25	0,49	0,49	1-MO.	115,0	56,35	31	1,5	MEC.	
1	20	IACCTC07-7207	1C	NC	04/04/24	30/05/25	4,86	4,86	1-MO.	115,0	558,90	31	1,5	MEC.	
1	21	IACCTC07-7207	1C	NC	05/04/24	30/05/25	4,76	4,76	1-MO.	115,0	547,40	31	1,5	MEC.	
1	22	IACCTC07-7207	1C	NC	04/04/24	30/05/25	4,92	4,92	1-MO.	115,0	565,80	31	1,5	MEC.	
1	23	IACCTC07-7207	1C	NC	03/04/24	30/05/25	1,61	1,61	1-MO.	115,0	185,15	31	1,5	MEC.	
1	24	IACCTC07-7207	1C	NC	03/04/24	30/05/25	2,77	2,77	1-MO.	115,0	318,55	31	1,5	MEC.	
1	25	IACCTC07-7207	1C	NC	05/04/24	30/05/25	1,86	1,86	1-MO.	115,0	213,90	31	1,5	MEC.	
1	26	IACCTC07-7207	1C	NC	05/04/24	30/05/25	0,04	0,04	1-MO.	115,0	4,60	31	1,5	MEC.	
1	27	IACCTC07-7207	1C	NC	05/04/24	30/05/25	1,06	1,06	1-MO.	115,0	121,90	31	1,5	MEC.	
1	28	IACCTC07-7207	1C	NC	05/04/24	30/05/25	0,96	0,96	1-MO.	115,0	110,40	31	1,5	MEC.	
1	29	IACCTC07-7207	1C	NC	03/04/24	30/05/25	4,80	4,80	1-MO.	115,0	552,00	31	1,5	MEC.	
1	30	CTC9007	1C	NC	05/04/24	30/05/25	12,96	12,96	1-MO.	115,0	1.490,40	31	1,5	MEC.	
1	31	CTC9007	1C	NC	06/04/24	30/05/25	17,63	17,63	1-MO.	115,0	2.027,45	31	1,5	MEC.	
1	32	CTC2994	1C	NC	15/03/24	30/05/25	7,32	7,32	1-MO.	115,0	841,80	31	1,5	MEC.	
1	33	CTC2994	1C	NC	15/03/24	30/05/25	10,99	10,99	1-MO.	115,0	1.263,85	31	1,5	MEC.	
Total/Média (3 / 550 · ROSA MISTICA)							209,99	209,99		115,0	24.148,85				

N: 7721219.773
E: 322873.6145
LAT: -20°36'0.6587" (-20.60018298)
LONG: -46°42'0.0385" (-46.70001069)

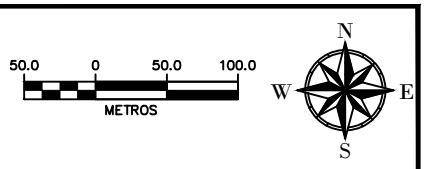

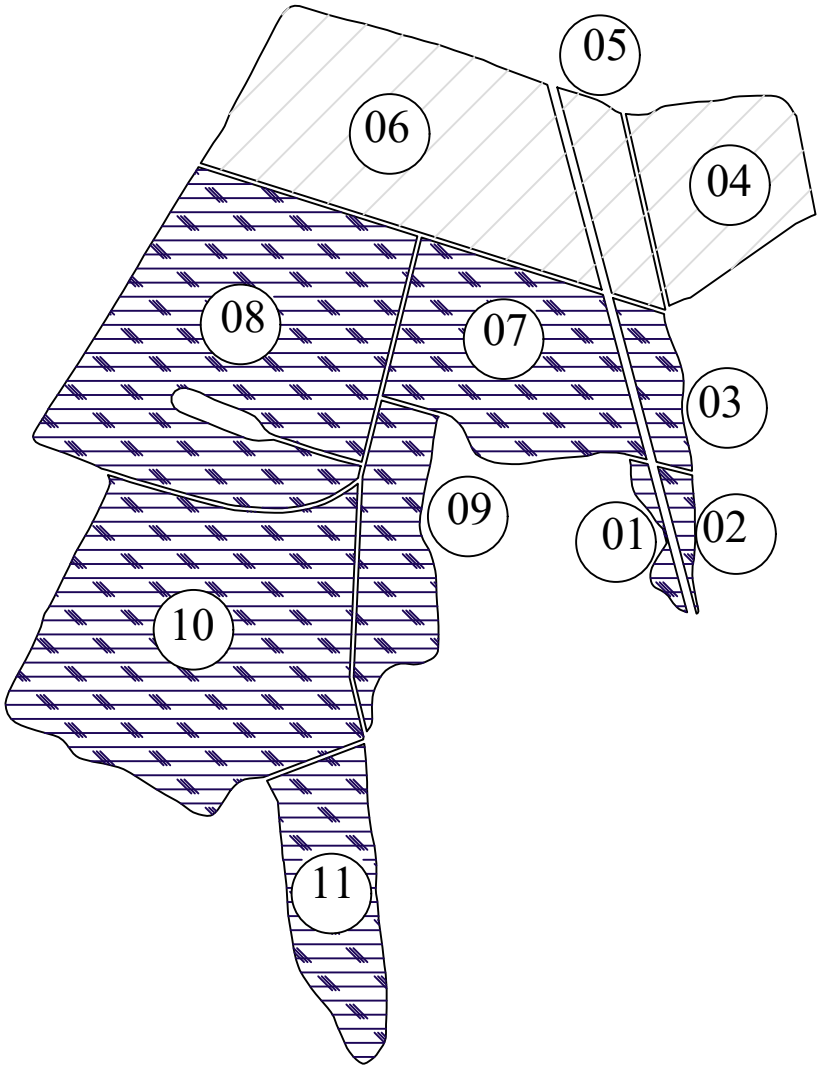

CV-7870
RB 86-7515

TABELA DE VARIEDADE	
VARIEDADE	ÁREA
CV7870	33,07
RB867515	12,69
Total Geral	**45,76**

IPIRANGA AGROINDUSTRIAL	PROJETO: CADERNO DE MAPA 25'26	DATA: 28-04-2023	ESCALA: 1:5000	TOPÓGRAFO: LUIS DUARTE
	FAZENDA: 552 - CASA BRANCA	MUNICÍPIO: PASSOS MG		ÁREA (ha): 45,76
	PROPRIETÁRIO: AGROPECUARIA IBIUBA	UNIDADE: IPIRANGA PASSOS		

Caderno de Mapas

Bloco	Talhao	Variedade	Estágio de Corte	Amb. Prod.	Data Plantio	Último Corte	Área (ha)	Estimativas Área (ha)	Finalid	Produt.	Prod. Total	Dist.	Esp.	Tipo Corte	Experimento
3 · REG 3			**552 · CASA BRANCA**				**JOSE IVALDO RODRIGUES NETO E OUTRO(S)**								
1	1	CV7870	2C	NC	11/12/22	01/08/25	0,28	0,28	1-MO.	95,0	26,60	25	1,5	MEC.	
1	2	CV7870	2C	NC	11/12/22	01/08/25	0,29	0,29	1-MO.	95,0	27,55	25	1,5	MEC.	
1	3	CV7870	2C	NC	11/12/22	01/08/25	0,88	0,88	1-MO.	95,0	83,60	25	1,5	MEC.	
1	4	RB867515	2C	NC	10/12/22	01/08/25	3,37	3,37	1-MO.	95,0	320,15	25	1,5	MEC.	
1	5	RB867515	2C	NC	10/12/22	01/08/25	1,38	1,38	1-MO.	95,0	131,10	25	1,5	MEC.	
1	6	RB867515	2C	NC	10/12/22	01/08/25	7,94	7,94	1-MO.	95,0	754,30	25	1,5	MEC.	
1	7	CV7870	2C	NC	11/12/22	01/08/25	5,05	5,05	1-MO.	95,0	479,75	25	1,5	MEC.	
1	8	CV7870	2C	NC	11/12/22	01/08/25	10,46	10,46	1-MO.	95,0	993,70	25	1,5	MEC.	
1	9	CV7870	2C	NC	12/12/22	01/08/25	2,40	2,40	1-MO.	95,0	228,00	25	1,5	MEC.	
1	10	CV7870	2C	NC	12/12/22	01/08/25	10,66	10,66	1-MO.	95,0	1.012,70	25	1,5	MEC.	
1	11	CV7870	2C	NC	12/12/22	01/08/25	3,05	3,05	1-MO.	95,0	289,75	25	1,5	MEC.	
Total/Média (3 / 552 · CASA BRANCA)							45,76	45,76		95,0	4.347,20				

N: 7721219.773
E: 322873.6145
LAT: -20°36'0.6587" (-20.60018298)
LONG: -46°42'0.0385" (-46.70001069)

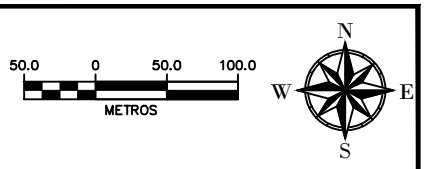

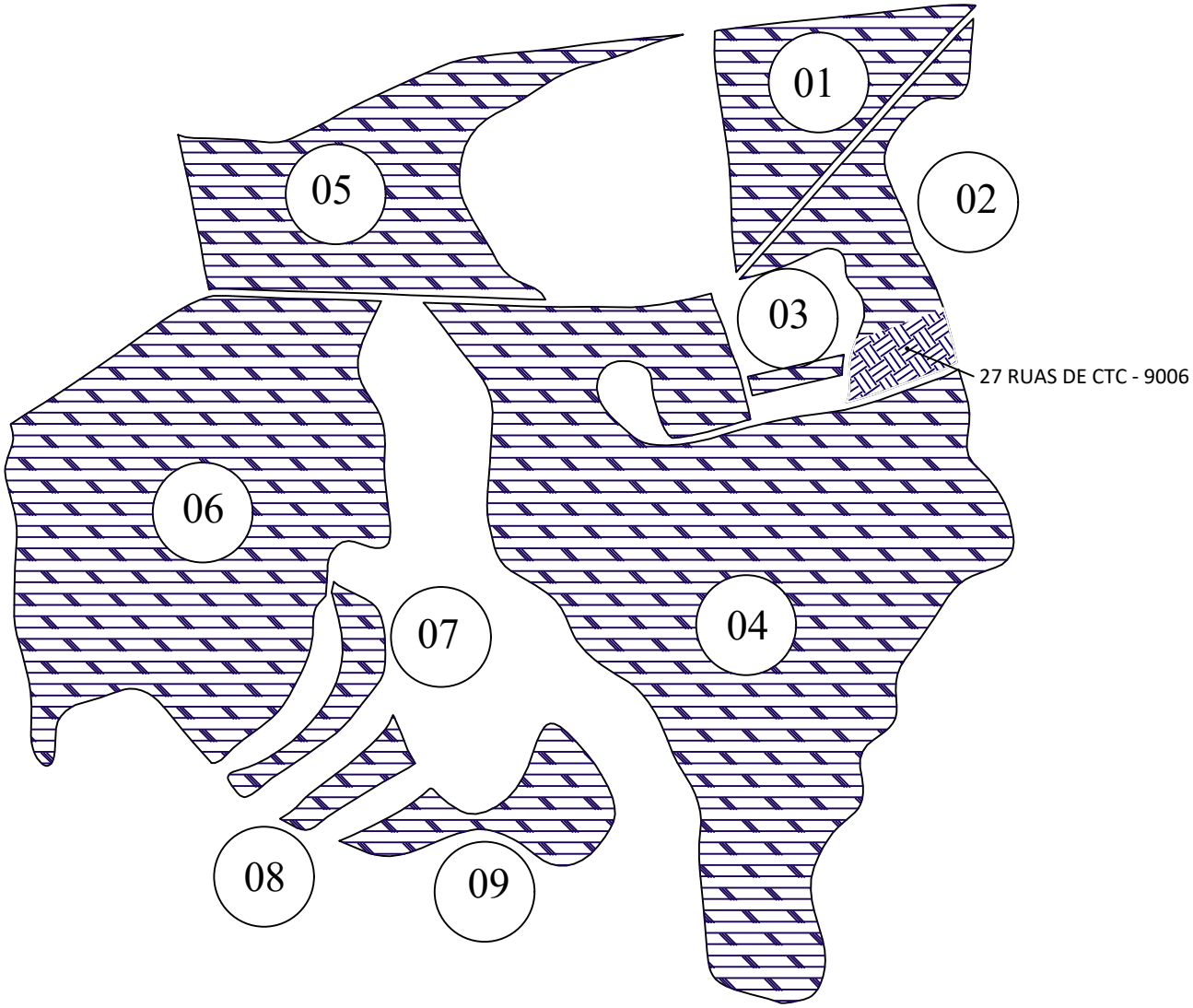

CV-7870
CTC - 9006

TABELA DE VARIEDADE	
VARIEDADE	ÁREA
CTC9006	0,30
CV7870	22,79
Total Geral	**23,09**

IPIRANGA AGROINDUSTRIAL

PROJETO: CADERNO DE MAPA 25'26	DATA: 08-08-2023	ESCALA: 1:5000	TOPÓGRAFO: LUIS DUARTE
FAZENDA: 553 - CASA BRANCA	MUNICÍPIO: PASSOS MG		ÁREA (ha): 23,09
PROPRIETÁRIO: ITAIQUARA ALIMENTOS	UNIDADE: IPIRANGA PASSOS		

Caderno de Mapas

Bloco	Talhao	Variedade	Estágio de Corte	Amb. Prod.	Data Plantio	Último Corte	Área (ha)	Estimativas Área (ha)	Finalid	Produt.	Prod. Total	Dist.	Esp.	Tipo Corte	Experimento
3 · REG 3			**553 · CASA BRANCA B**				**JOSE IVALDO RODRIGUES NETO E OUTRO(S)**								
1	1	CV7870	2C	NC	02/09/22	01/08/25	1,59	1,59	1-MO.	95,0	151,05	25	1,5	MEC.	
1	2	CV7870	2C	NC	02/09/22	01/08/25	0,41	0,41	1-MO.	95,0	38,95	25	1,5	MEC.	
1	3	CV7870	2C	NC	03/09/22	01/08/25	9,04	9,04	1-MO.	95,0	858,80	25	1,5	MEC.	
1	4	CV7870	2C	NC	02/09/22	01/08/25	2,83	2,83	1-MO.	95,0	268,85	25	1,5	MEC.	
1	5	CV7870	2C	NC	02/09/22	01/08/25	6,14	6,14	1-MO.	95,0	583,30	25	1,5	MEC.	
1	6	CV7870	2C	NC	02/09/22	01/08/25	0,38	0,38	1-MO.	95,0	36,10	25	1,5	MEC.	
1	7	CV7870	2C	NC	02/09/22	01/08/25	0,21	0,21	1-MO.	95,0	19,95	25	1,5	MEC.	
1	8	CV7870	2C	NC	02/09/22	01/08/25	0,69	0,69	1-MO.	95,0	65,55	25	1,5	MEC.	
1	9	CV7870	2C	NC	02/09/22	01/08/25	0,74	0,74	1-MO.	95,0	70,30	25	1,5	MEC.	
Total/Média (3 / 553 · CASA BRANCA B)							22,03	22,03		95,0	2.092,85				

N: 7728438.809
E: 333950.4745
LAT: −20°32'9.5585" (−20.53598848)
LONG: −46°35'35.0775" (−46.59307710)

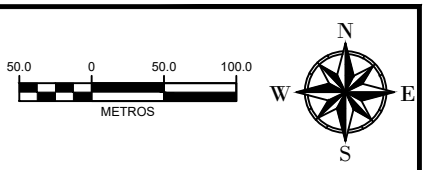

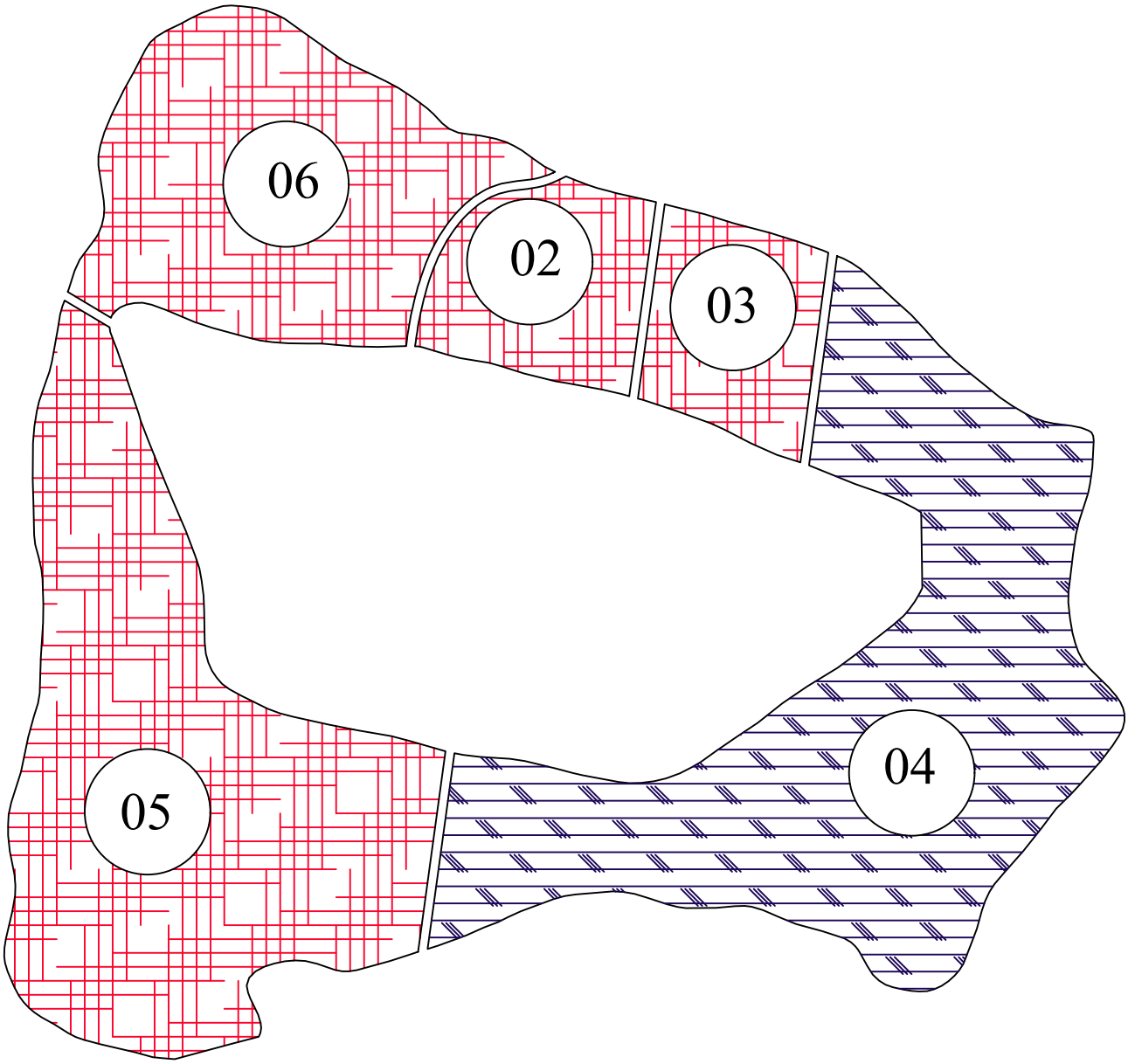

CV-7870

IAC SP 01-5503

TABELA DE VARIEDADE

VARIEDADE	ÁREA
CV7870	6,06
IACSP01-5503	15,42
Total Geral	**21,48**

IPIRANGA AGROINDUSTRIAL

PROJETO: CADERNO DE MAPA 25'26	DATA: 05-08-2022	ESCALA: 1:5000	TOPÓGRAFO: LUIS DUARTE
FAZENDA: 554 - BERALDINHO II	MUNICÍPIO: DELFINOPOLIS MG		ÁREA (ha): 21,48
PROPRIETÁRIO:	UNIDADE: IPIRANGA PASSOS MG		

Caderno de Mapas

Bloco	Talhao	Variedade	Estágio de Corte	Amb. Prod.	Data Plantio	Último Corte	Área (ha)	Estimativas Área (ha)	Finalid	Produt.	Prod. Total	Dist.	Esp.	Tipo Corte	Experimento
3 · REG 3			**554 · BERALDINHO II**				**JOSE IVALDO RODRIGUES NETO E OUTRO(S)**								
1	1	IACSP01-5503	1C	NC	07/11/23	05/08/25	4,67	4,67	1-MO.	90,0	420,30	27	1,5	MEC.	
1	2	IACSP01-5503	2C	NC	13/12/22	05/08/25	1,18	1,18	1-MO.	90,0	106,20	27	1,5	MEC.	
1	3	IACSP01-5503	2C	NC	14/12/22	05/08/25	1,07	1,07	1-MO.	90,0	96,30	27	1,5	MEC.	
1	4	CV7870	2C	NC	15/12/22	05/08/25	6,06	6,06	1-MO.	90,0	545,40	27	1,5	MEC.	
1	5	IACSP01-5503	2C	NC	13/12/22	05/08/25	5,39	5,39	1-MO.	90,0	485,10	27	1,5	MEC.	
1	6	IACSP01-5503	2C	NC	13/12/22	05/08/25	3,11	3,11	1-MO.	90,0	279,90	27	1,5	MEC.	
Total/Média (3 / 554 · BERALDINHO II)							21,48	21,48		90,0	1.933,20				

N: 7727247.34296519
E: 337039.98843325
LAT: −20°32'49.2735328" (−20.54702042577)
LONG: −46°33'48.8203356" (−46.56356120433)

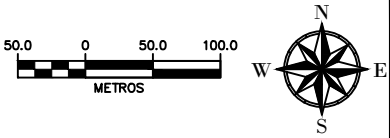

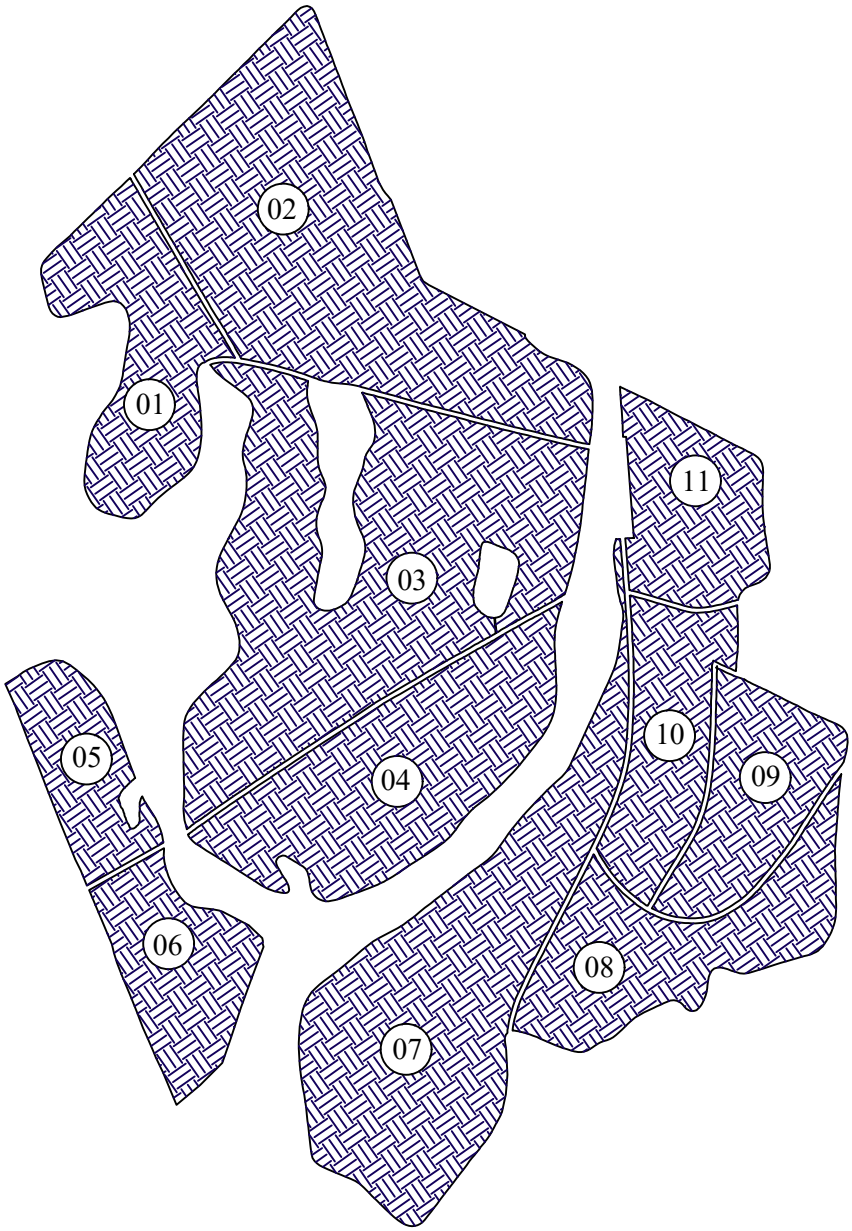

CTC - 9006

TABELA DE VARIEDADE	
VARIEDADE	ÁREA
CTC9006	45,60
Total Geral	**45,60**

IPIRANGA AGROINDUSTRIAL	PROJETO: CADERNO DE MAPA 25'26	DATA: 27/03/2025	ESCALA: 1:5000	TOPÓGRAFO: LUIS DUARTE
	FAZENDA: 555 - RIBEIRÃO GRANDE	MUNICÍPIO: DELFINOPOLIS - MG	ÁREA (ha): 45,60
	PROPRIETÁRIO: IVALTENIR FRANCISCO M RODRIGUES	UNIDADE: IPIRANGA PASSOS	

Caderno de Mapas

Bloco	Talhao	Variedade	Estágio de Corte	Amb. Prod.	Data Plantio	Data Último Corte	Área (ha)	Estimativas Área (ha)	Estimativas Finalid	Estimativas Produt.	Prod. Total	Dist.	Esp.	Tipo Corte	Experimento
3 · REG 3			**555 · RIBEIRÃO GRANDE**				**IVALTENIR FRANCISCO MAIA RODRIGUES**								
1	1	CTC9006	FORM	NC	11/03/25		3,05	0,00	.		0,00	23,5	1,5	N/D	
1	2	CTC9006	FORM	NC	10/03/25		8,04	0,00	.		0,00	23,5	1,5	N/D	
1	3	CTC9006	FORM	NC	11/03/25		8,85	0,00	.		0,00	23,5	1,5	N/D	
1	4	CTC9006	FORM	NC	08/03/25		4,70	0,00	.		0,00	23,5	1,5	N/D	
1	5	CTC9006	FORM	NC	12/03/25		1,69	0,00	.		0,00	23,5	1,5	N/D	
1	6	CTC9006	FORM	NC	12/03/25		2,21	0,00	.		0,00	23,5	1,5	N/D	
1	7	CTC9006	FORM	NC	08/03/25		6,85	0,00	.		0,00	23,5	1,5	N/D	
1	8	CTC9006	FORM	NC	08/03/25		3,28	0,00	.		0,00	23,5	1,5	N/D	
1	9	CTC9006	FORM	NC	08/03/25		2,31	0,00	.		0,00	23,5	1,5	N/D	
1	10	CTC9006	FORM	NC	10/03/25		2,31	0,00	.		0,00	23,5	1,5	N/D	
1	11	CTC9006	FORM	NC	10/03/25		2,31	0,00	.		0,00	23,5	1,5	N/D	
Total/Média (3 / 555 · RIBEIRÃO GRANDE)							45,60	0,00			0,00				

N: 7727247.34296519
E: 337039.98843325
LAT: −20°32'49.2735328" (−20.54702042577)
LONG: −46°33'48.8203356" (−46.56356120433)

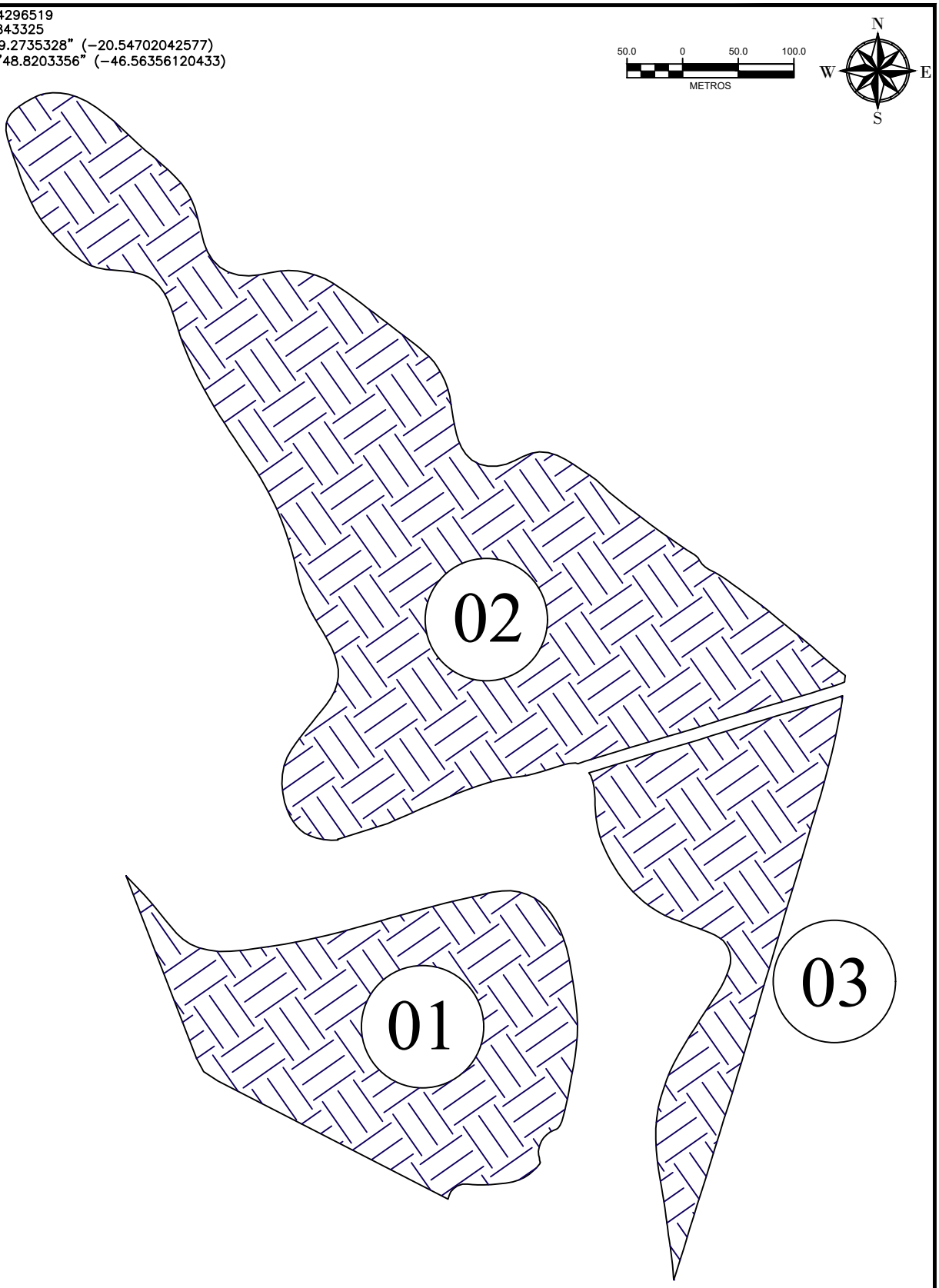

CTC - 9006

TABELA DE VARIEDADE	
VARIEDADE	ÁREA
CTC9006	5,79
Total Geral	**5,79**

IPIRANGA AGROINDUSTRIAL

PROJETO: CADERNO DE MAPA 25'26	DATA: 27/03/2025	ESCALA: 1:5000	TOPÓGRAFO: LUIS DUARTE
FAZENDA: 556 - BOM JESUS DA LAPA	MUNICÍPIO: DEFINOPOLIS MG		ÁREA (ha): 5,79
PROPRIETÁRIO:	UNIDADE: IPIRANGA PASSOS S.A.		

Caderno de Mapas

Bloco	Talhao	Variedade	Estágio de Corte	Amb. Prod.	Data Plantio	Último Corte	Área (ha)	Estimativas Área (ha)	Finalid	Produt.	Prod. Total	Dist.	Esp.	Tipo Corte	Experimento
3 · REG 3			**556 · BOM JESUS LAPA**				**IVALTENIR FRANCISCO MAIA RODRIGUES**								
1	1	CTC9006	FORM	NC	11/03/25		1,47	0,00	.		0,00	23,5	1,5	N/D	
1	2	CTC9006	FORM	NC	11/03/25		3,40	0,00	.		0,00	23,5	1,5	N/D	
1	3	CTC9006	FORM	NC	11/03/25		0,92	0,00	.		0,00	23,5	1,5	N/D	
Total/Média (3 / 556 · BOM JESUS LAPA)							5,79	0,00			0,00				

N: 7713853.634
E: 335030.8915
LAT: −20°40'4.1716" (−20.66782545)
LONG: −46°35'2.6806" (−46.58407794)

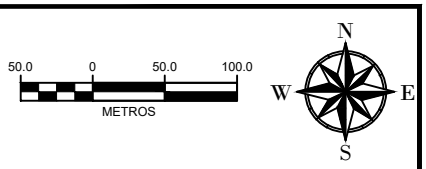

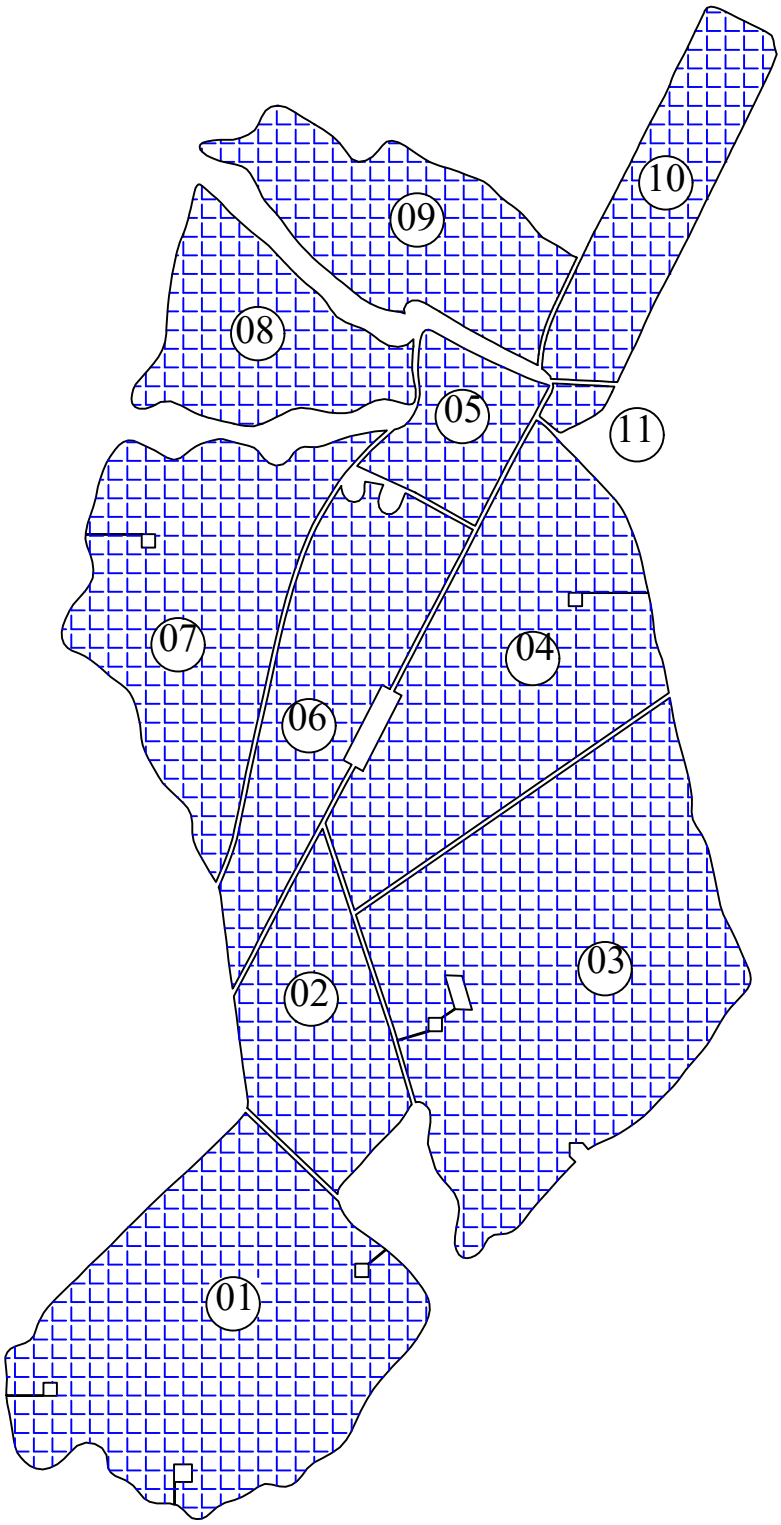

CTC - 2

TABELA DE VARIEDADE	
VARIEDADE	ÁREA
CTC2	72,79
Total Geral	**72,79**

IPIRANGA AGROINDUSTRIAL

PROJETO: CADERNO DE MAPA 25'26	DATA: 17-10-2022	ESCALA: 1:5000	TOPÓGRAFO: LUIS DUARTE
FAZENDA: 557 CAMPOS / SERRINHA	MUNICÍPIO: DELFINOPOLIS MG		ÁREA (ha): 72,79
PROPRIETÁRIO:	UNIDADE: IPIRANGA PASSOS S.A.		

Caderno de Mapas

Bloco	Talhao	Variedade	Estágio de Corte	Amb. Prod.	Data Plantio	Último Corte	Área (ha)	Estimativas Área (ha)	Finalid	Produt.	Prod. Total	Dist.	Esp.	Tipo Corte	Experimento
3 · REG 3			**557 · CAMPOS/SERRINHA**				**IVALTENIR FRANCISCO MAIA RODRIGUES**								
1	1	CTC2	2C	NC	19/03/23	04/07/25	12,58	12,58	1-MO.	95,0	1.195,10	32	1,5	MEC.	
1	2	CTC2	2C	NC	19/03/23	04/07/25	4,57	4,57	1-MO.	95,0	434,15	32	1,5	MEC.	
1	3	CTC2	2C	NC	19/03/23	04/07/25	14,98	14,98	1-MO.	95,0	1.423,10	32	1,5	MEC.	
1	4	CTC2	2C	NC	19/03/23	04/07/25	9,82	9,82	1-MO.	95,0	932,90	32	1,5	MEC.	
1	5	CTC2	2C	NC	19/03/23	04/07/25	2,32	2,32	1-MO.	95,0	220,40	32	1,5	MEC.	
1	6	CTC2	2C	NC	19/03/23	04/07/25	5,93	5,93	1-MO.	95,0	563,35	32	1,5	MEC.	
1	7	CTC2	2C	NC	19/03/23	04/07/25	8,25	8,25	1-MO.	95,0	783,75	32	1,5	MEC.	
1	8	CTC2	FORM	NC	11/11/24		4,47	0,00	.		0,00	32	1,5	N/D	
1	9	CTC2	FORM	NC	09/11/24		5,40	0,00	.		0,00	32	1,5	N/D	
1	10	CTC2	FORM	NC	12/11/24		4,18	0,00	.		0,00	32	1,5	N/D	
1	11	CTC2	FORM	NC	12/11/24		0,29	0,00	.		0,00	32	1,5	N/D	
Total/Média (3 / 557 · CAMPOS/SERRINHA)							72,79	58,45		95,0	5.552,75				

N: 7713853.634
E: 335030.8915
LAT: −20°40'4.1716" (−20.66782545)
LONG: −46°35'2.6806" (−46.58407794)

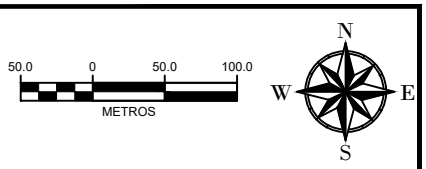

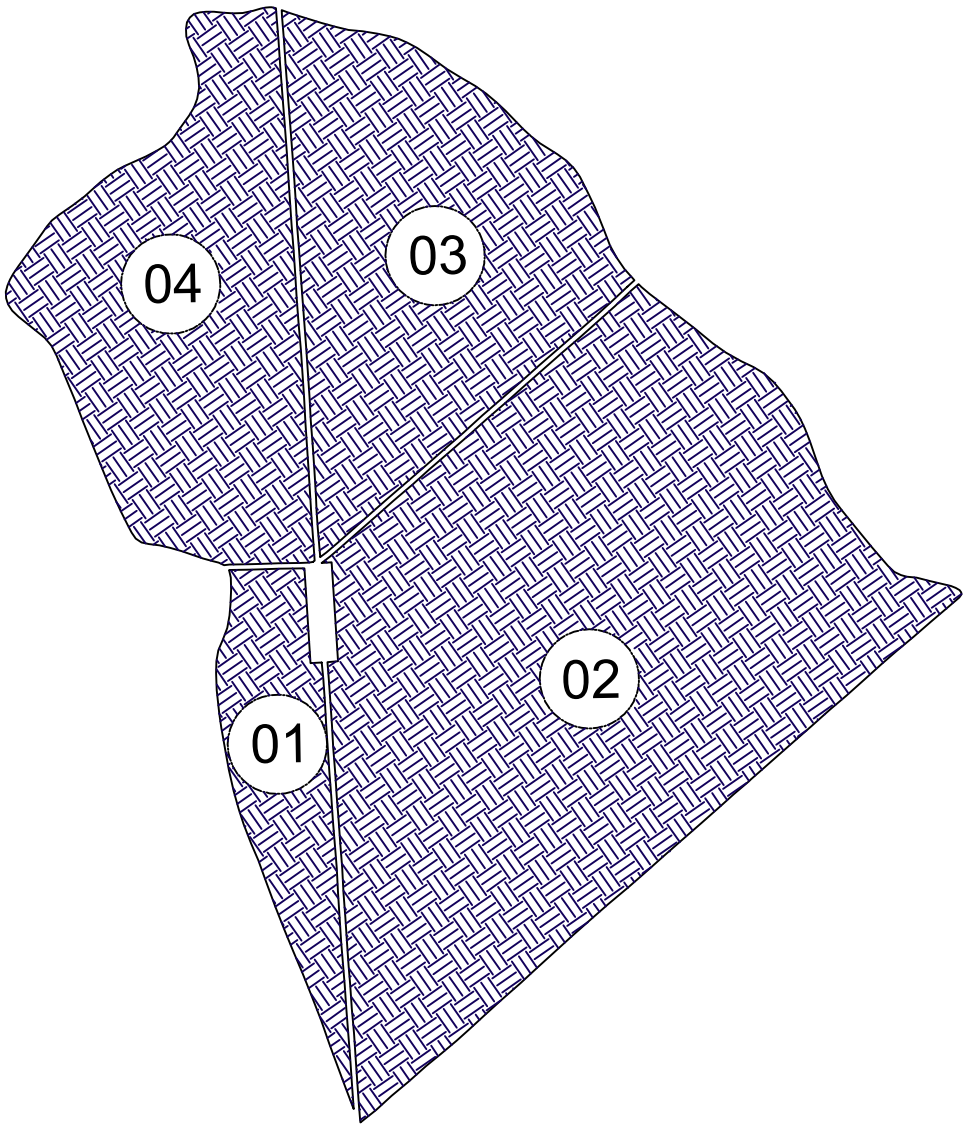

CTC - 9006

TABELA DE VARIEDADE	
VARIEDADE	ÁREA
CTC9006	42,81
Total Geral	**42,81**

IPIRANGA AGROINDUSTRIAL	PROJETO: CADERNO DE MAPA 25´26	DATA: 16-07-2025 / ESCALA: 1:5000	TOPÓGRAFO: CRISTIAN
	FAZENDA: 558 - FLORESTA	MUNICÍPIO: PASSOS - MG	ÁREA (ha): 42,81
	PROPRIETÁRIO: MARCOS TADEU	UNIDADE: IPIRANGA PASSOS S.A.	

Caderno de Mapas

Bloco	Talhao	Variedade	Estágio de Corte	Amb. Prod.	Data Plantio	Último Corte	Área (ha)	Estimativas Área (ha)	Finalid	Produt.	Prod. Total	Dist.	Esp.	Tipo Corte	Experimento
3 · REG 3			**558 · FLORESTA**				**MARCOS TADEU MIRANDA CARVALHO**								
1	1	CTC9006	1C	NC	20/03/24	26/01/25	3,00	3,00	2-MU.	50,0	150,00	39	1,5	MEC.	
1	2	CTC9006	1C	NC	21/03/24	09/05/25	22,27	1,93	1-MO.	105,0	202,65	39	1,5	MEC.	
1	2	CTC9006	1C	NC	21/03/24	09/05/25	22,27	20,34	2-MU.	50,0	1.017,00	39	1,5	MEC.	
1	3	CTC9006	1C	NC	30/03/24	09/05/25	8,92	1,91	1-MO.	105,0	200,55	39	1,5	MEC.	
1	3	CTC9006	1C	NC	30/03/24	09/05/25	8,92	7,01	2-MU.	50,0	350,50	39	1,5	MEC.	
1	4	CTC9006	1C	NC	19/03/24	26/01/25	8,62	8,62	2-MU.	50,0	431,00	39	1,5	MEC.	
Total/Média (3 / 558 · FLORESTA)							42,81	42,81		54,9	2.351,70				

N: 7726766.68041394
E: 336863.74250854
LAT: −20°33'4.8487089" (−20.55134686357)
LONG: −46°33'55.0640440" (−46.56529556778)

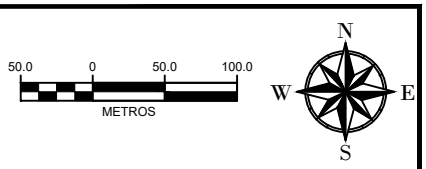

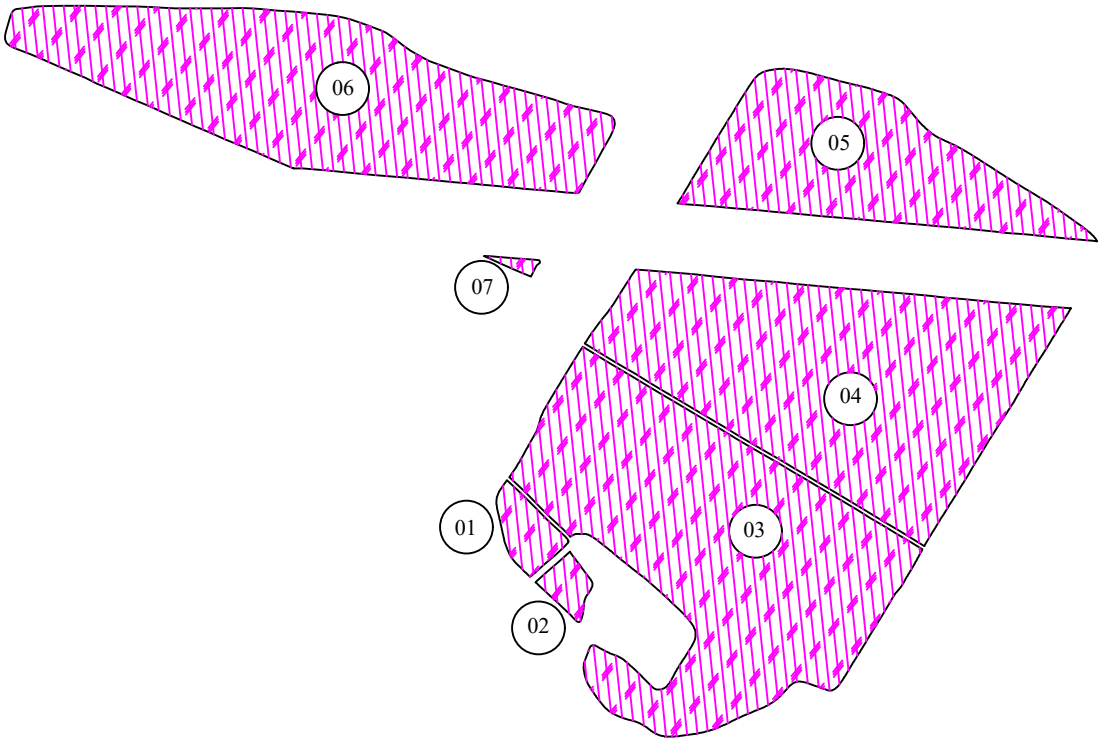

CTC -2994

TABELA DE VARIEDADE	
VARIEDADE	ÁREA
CTC2994	45,93
Total Geral	**45,93**

IPIRANGA AGROINDUSTRIAL	PROJETO: CADERNO DE MAPA 25'26	DATA: 16-07-2025	ESCALA: 1:5000	TOPÓGRAFO: CRISTIAN
	FAZENDA: 559 - SÃO FRANCISCO	MUNICÍPIO: PASSOS - MG		ÁREA (ha): 45,93
	PROPRIETÁRIO: NEY	UNIDADE: IPIRANGA PASSOS S.A.		

Caderno de Mapas

Bloco	Talhao	Variedade	Estágio de Corte	Amb. Prod.	Data Plantio	Último Corte	Área (ha)	Estimativas Área (ha)	Finalid	Produt.	Prod. Total	Dist.	Esp.	Tipo Corte	Experimento
3 · REG 3			**559 · SAO FRANCISCO**				**MARIA EDUARDA DE SOUZA CAPATO**								
1	1	CTC2994	1C	NC	15/03/24	02/05/25	0,64	0,64	1-MO.	130,0	83,20	11	1,5	MEC.	
1	2	CTC2994	1C	NC	15/03/24	02/05/25	0,35	0,35	1-MO.	130,0	45,50	11	1,5	MEC.	
1	3	CTC2994	1C	NC	14/03/24	02/05/25	14,02	14,02	1-MO.	130,0	1.822,60	11	1,5	MEC.	
1	4	CTC2994	1C	NC	16/03/24	02/05/25	12,80	12,80	1-MO.	130,0	1.664,00	11	1,5	MEC.	
1	5	CTC2994	1C	NC	17/03/24	02/05/25	6,52	6,52	1-MO.	130,0	847,60	11	1,5	MEC.	
1	6	CTC2994	1C	NC	17/03/24	02/05/25	11,52	11,52	1-MO.	130,0	1.497,60	11	1,5	MEC.	
1	7	CTC2994	1C	NC	16/03/24	02/05/25	0,08	0,08	1-MO.	130,0	10,40	11	1,5	MEC.	
Total/Média (3 / 559 · SAO FRANCISCO)							45,93	45,93		130,0	5.970,90				

N: 7720407.51907686
E: 331755.71815115
LAT: −20°36'30.0109764" (−20.60833638234)
LONG: −46°36'53.5866714" (−46.61488518649)

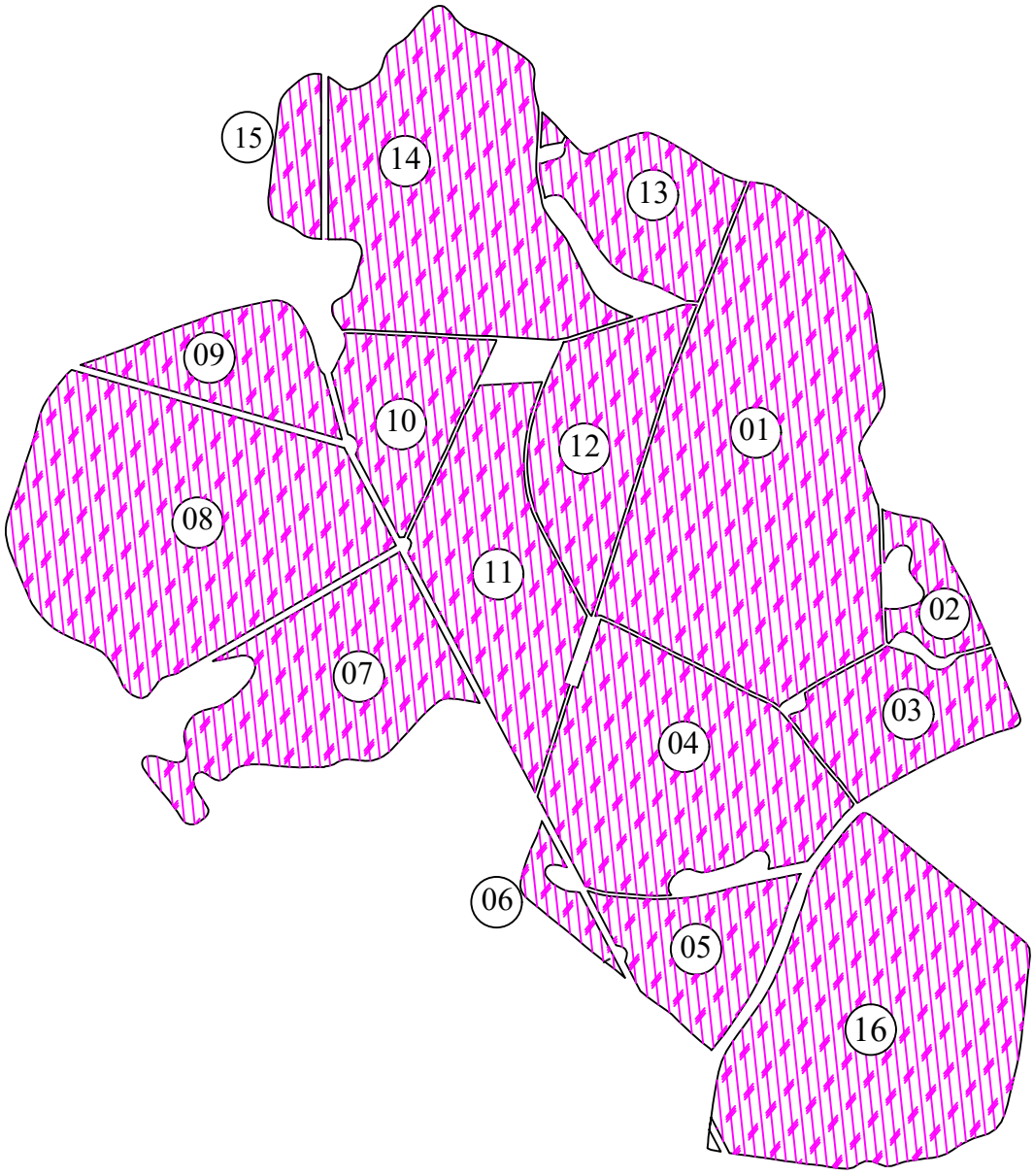

TABELA DE VARIEDADE	
VARIEDADE	ÁREA
CTC2994	113,31
Total Geral	**113,31**

CTC -2994

IPIRANGA AGROINDUSTRIAL

PROJETO: CADERNO DE MAPA 25´26	DATA: 16-07-2025	ESCALA: 1:5000	TOPÓGRAFO: CRISTIAN
FAZENDA: 560 - CONQUISTA	MUNICÍPIO: PASSOS - MG		ÁREA (ha): 113,31
PROPRIETÁRIO: ALTAIR JOSÉ CAPATO	UNIDADE: IPIRANGA PASSOS S.A.		

Caderno de Mapas

Bloco	Talhao	Variedade	Estágio de Corte	Amb. Prod.	Data Plantio	Data Último Corte	Área (ha)	Estimativas Área (ha)	Estimativas Finalid	Estimativas Produt.	Prod. Total	Dist.	Esp.	Tipo Corte	Experimento
3 · REG 3			**560 · CONQUISTA**				**MARIA EDUARDA DE SOUZA CAPATO**								
1	1	CTC2994	1C	NC	16/01/24	17/06/25	18,91	18,91	1-MO.	130,0	2.458,30	14	1,5	MEC.	
1	2	CTC2994	1C	NC	02/01/24	17/06/25	1,56	1,56	1-MO.	130,0	202,80	14	1,5	MEC.	
1	3	CTC2994	1C	NC	02/01/24	17/06/25	4,04	4,04	1-MO.	130,0	525,20	14	1,5	MEC.	
1	4	CTC2994	1C	NC	31/01/24	17/06/25	10,31	10,31	1-MO.	130,0	1.340,30	14	1,5	MEC.	
1	5	CTC2994	1C	NC	30/01/24	17/06/25	3,69	3,69	1-MO.	130,0	479,70	14	1,5	MEC.	
1	6	CTC2994	1C	NC	04/01/24	17/06/25	0,82	0,82	1-MO.	130,0	106,60	14	1,5	MEC.	
1	7	CTC2994	1C	NC	30/12/23	17/06/25	7,37	7,37	1-MO.	130,0	958,10	14	1,5	MEC.	
1	8	CTC2994	1C	NC	11/02/24	17/06/25	15,03	15,03	1-MO.	130,0	1.953,90	14	1,5	MEC.	
1	9	CTC2994	1C	NC	31/12/23	17/06/25	3,43	3,43	1-MO.	130,0	445,90	14	1,5	MEC.	
1	10	CTC2994	1C	NC	31/12/23	17/06/25	3,62	3,62	1-MO.	130,0	470,60	14	1,5	MEC.	
1	11	CTC2994	1C	NC	01/02/24	17/06/25	7,17	7,17	1-MO.	130,0	932,10	14	1,5	MEC.	
1	12	CTC2994	1C	NC	30/12/23	17/06/25	5,11	5,11	1-MO.	130,0	664,30	14	1,5	MEC.	
1	13	CTC2994	1C	NC	30/12/23	17/06/25	4,05	0,02	2-MU.	50,0	1,00	14	1,5	MEC.	
1	13	CTC2994	1C	NC	30/12/23	17/06/25	4,05	4,03	1-MO.	130,0	523,90	14	1,5	MEC.	
1	14	CTC2994	1C	NC	21/02/24	17/06/25	12,26	3,08	2-MU.	50,0	154,00	14	1,5	MEC.	
1	14	CTC2994	1C	NC	21/02/24	17/06/25	12,26	9,18	1-MO.	130,0	1.193,40	14	1,5	MEC.	
1	15	CTC2994	1C	NC	21/02/24	17/06/25	1,33	1,33	1-MO.	130,0	172,90	14	1,5	MEC.	
1	16	CTC2994	FORM	NC	12/01/25		14,61	0,00	.		0,00	14	1,5	N/D	
Total/Média (3 / 560 · CONQUISTA)							113,31	98,70		127,5	12.583,00				

N: 7713853.634
E: 335030.8915
LAT: −20°40'4.1716" (−20.66782545)
LONG: −46°35'2.6806" (−46.58407794)

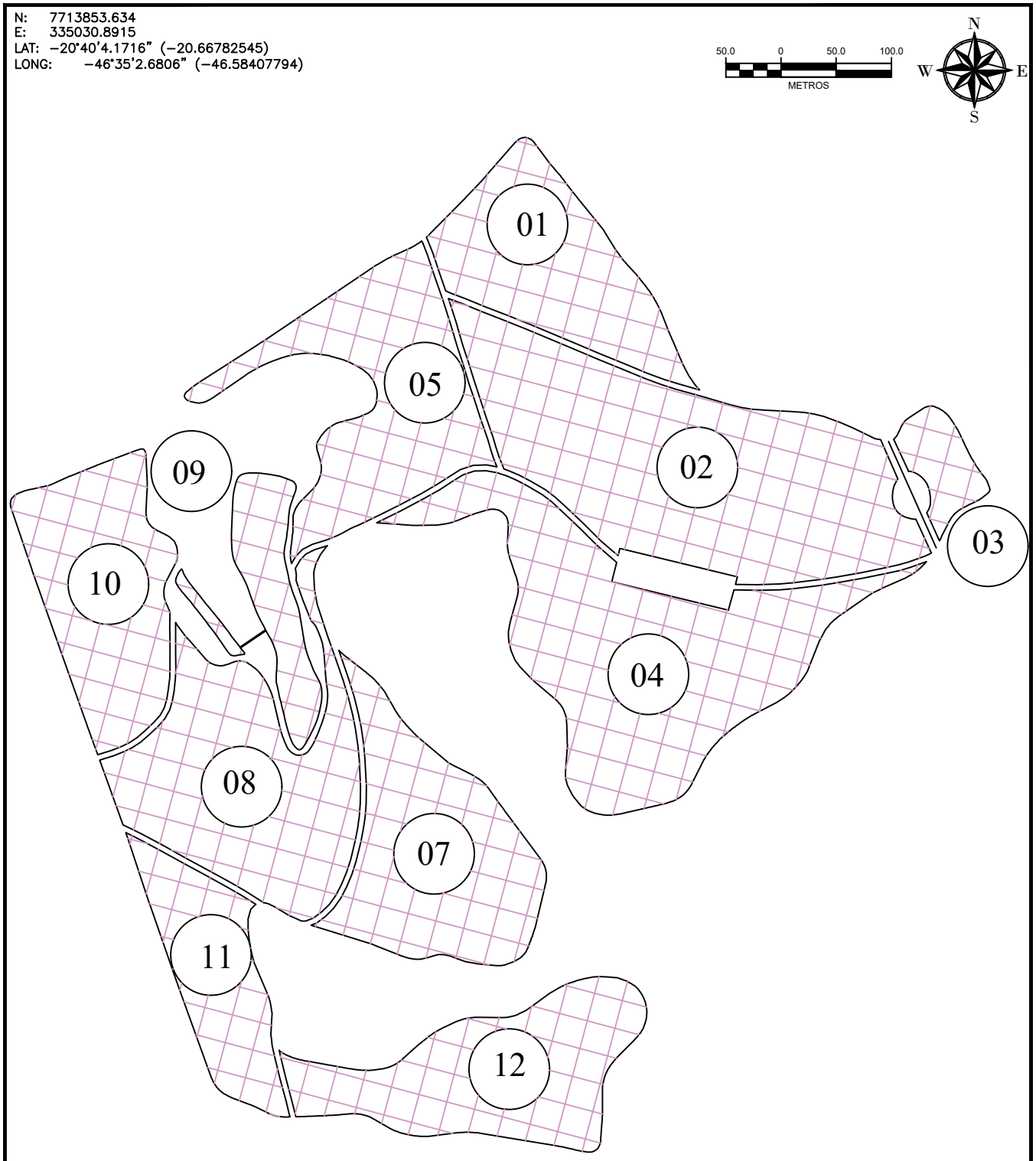

TABELA DE VARIEDADE	
VARIEDADE	ÁREA
IACCTC07-7207	29,03
Total Geral	**29,03**

IAC CTC 07-7207

IPIRANGA AGROINDUSTRIAL

PROJETO: CADERNO DE MAPA 25´26	DATA: 16-07-2025	ESCALA: 1:5000	TOPÓGRAFO: CRISTIAN
FAZENDA: 561 - BOCA DA MATA	MUNICÍPIO: PASSOS - MG		ÁREA (ha): 29,03
PROPRIETÁRIO: MARCOS TADEU MIRANDA CARVALHO	UNIDADE: IPIRANGA PASSOS S.A.		

Caderno de Mapas

Bloco	Talhao	Variedade	Estágio de Corte	Amb. Prod.	Data Plantio	Último Corte	Área (ha)	Estimativas Área (ha)	Finalid	Produt.	Prod. Total	Dist.	Esp.	Tipo Corte	Experimento
3 · REG 3			**561 · BOCA DA MATA**				**MARCOS TADEU MIRANDA CARVALHO**								
1	1	IACCTC07-7207	1C	NC	21/02/24	12/02/25	2,27	2,27	2-MU.	70,0	158,90	29	1,5	MEC.	
1	2	IACCTC07-7207	1C	NC	23/02/24	01/07/25	5,25	5,25	1-MO.	100,0	525,00	29	1,5	MEC.	
1	3	IACCTC07-7207	1C	NC	26/02/24	01/07/25	0,47	0,47	1-MO.	100,0	47,00	29	1,5	MEC.	
1	4	IACCTC07-7207	1C	NC	26/02/24	12/02/25	4,64	4,64	2-MU.	70,0	324,80	29	1,5	MEC.	
1	5	IACCTC07-7207	1C	NC	21/02/24	01/07/25	2,75	2,75	1-MO.	120,0	330,00	29	1,5	MEC.	
1	7	IACCTC07-7207	1C	NC	23/02/24	01/07/25	2,78	2,78	1-MO.	120,0	333,60	29	1,5	MEC.	
1	8	IACCTC07-7207	1C	NC	24/02/24	01/07/25	3,39	3,39	1-MO.	120,0	406,80	29	1,5	MEC.	
1	9	CTC9009	FORM	NC	25/03/25		0,97	0,00	.		0,00	29	1,5	N/D	
1	10	IACCTC07-7207	1C	NC	23/02/24	01/07/25	2,38	2,38	1-MO.	120,0	285,60	29	1,5	MEC.	
1	11	IACCTC07-7207	1C	NC	24/02/24	01/07/25	1,52	1,52	1-MO.	120,0	182,40	29	1,5	MEC.	
1	12	IACCTC07-7207	1C	NC	24/02/24	01/07/25	2,61	2,61	1-MO.	120,0	313,20	29	1,5	MEC.	
Total/Média (3 / 561 · BOCA DA MATA)							29,03	28,06		103,6	2.907,30				

N: 7713853.634
E: 335030.8915
LAT: −20°40'4.1716" (−20.66782545)
LONG: −46°35'2.6806" (−46.58407794)

50.0 0 50.0 100.0
METROS

N
W E
S

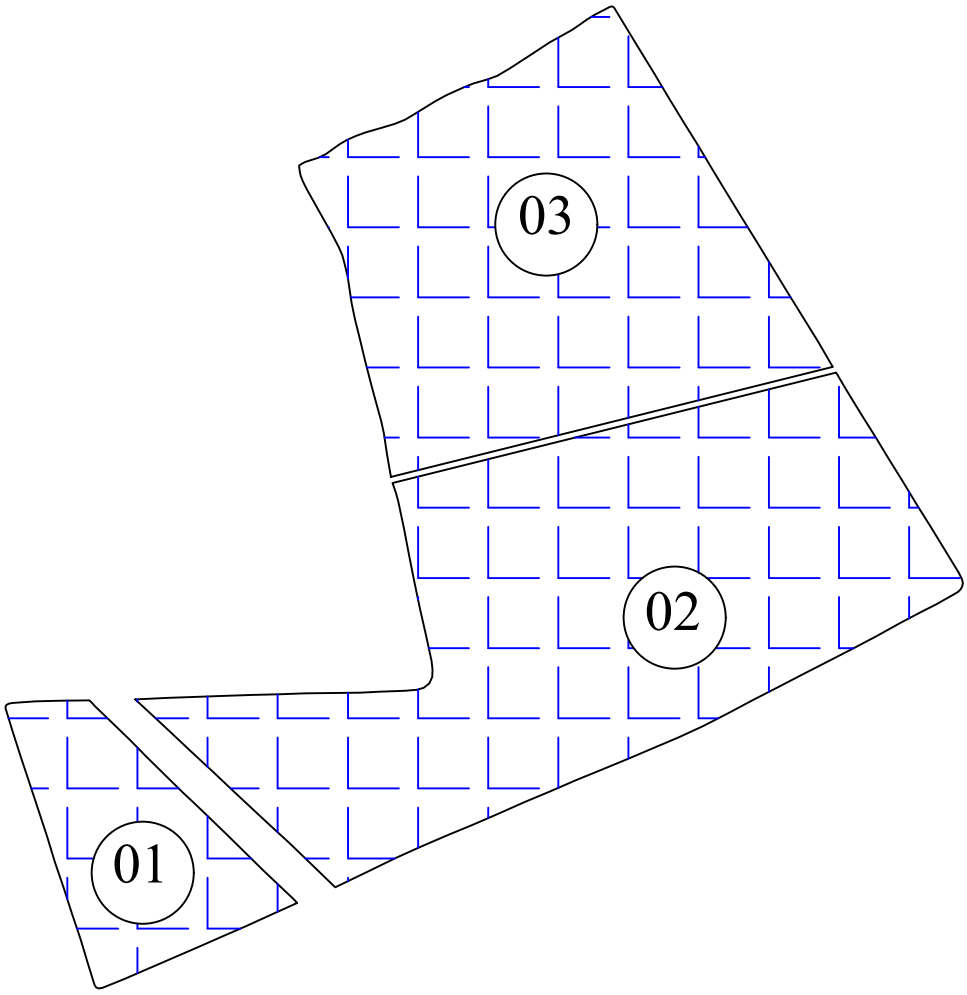

CTC - 2

TABELA DE VARIEDADE	
VARIEDADE	ÁREA
CTC2	23,11
Total Geral	**23,11**

IPIRANGA AGROINDUSTRIAL	PROJETO: CADERNO DE MAPA 25´26	DATA: 16-07-2025 / ESCALA: 1:5000	TOPÓGRAFO: CRISTIAN
	FAZENDA: 562 - BARRO PRETO	MUNICÍPIO: PASSOS - MG	ÁREA (ha): 23,11
	PROPRIETÁRIO: MARIA CRISTINA DE FREITAS BERALDO	UNIDADE: IPIRANGA PASSOS S.A.	

Caderno de Mapas

Bloco	Talhao	Variedade	Estágio de Corte	Amb. Prod.	Data Plantio	Último Corte	Área (ha)	Estimativas Área (ha)	Finalid	Produt.	Prod. Total	Dist.	Esp.	Tipo Corte	Experimento
3 · REG 3			**562 · BARRO PRETO**				**MARIA CRISTINA DE FREITAS BERALDO**								
1	1	CTC2	1C	NC	26/10/23	02/04/25	2,56	2,56	1-MO.	130,0	332,80	39	1,5	MEC.	
1	2	CTC2	1C	NC	30/10/23	02/04/25	11,74	11,74	1-MO.	130,0	1.526,20	39	1,5	MEC.	
1	3	CTC2	1C	NC	31/10/23	02/04/25	8,81	8,81	1-MO.	130,0	1.145,30	39	1,5	MEC.	
Total/Média (3 / 562 · BARRO PRETO)							23,11	23,11		130,0	3.004,30				

N: 7713853.634
E: 335030.8915
LAT: −20°40'4.1716" (−20.66782545)
LONG: −46°35'2.6806" (−46.58407794)

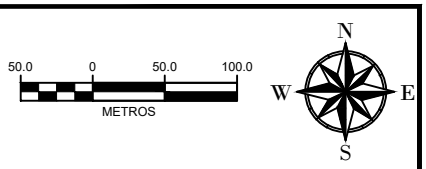

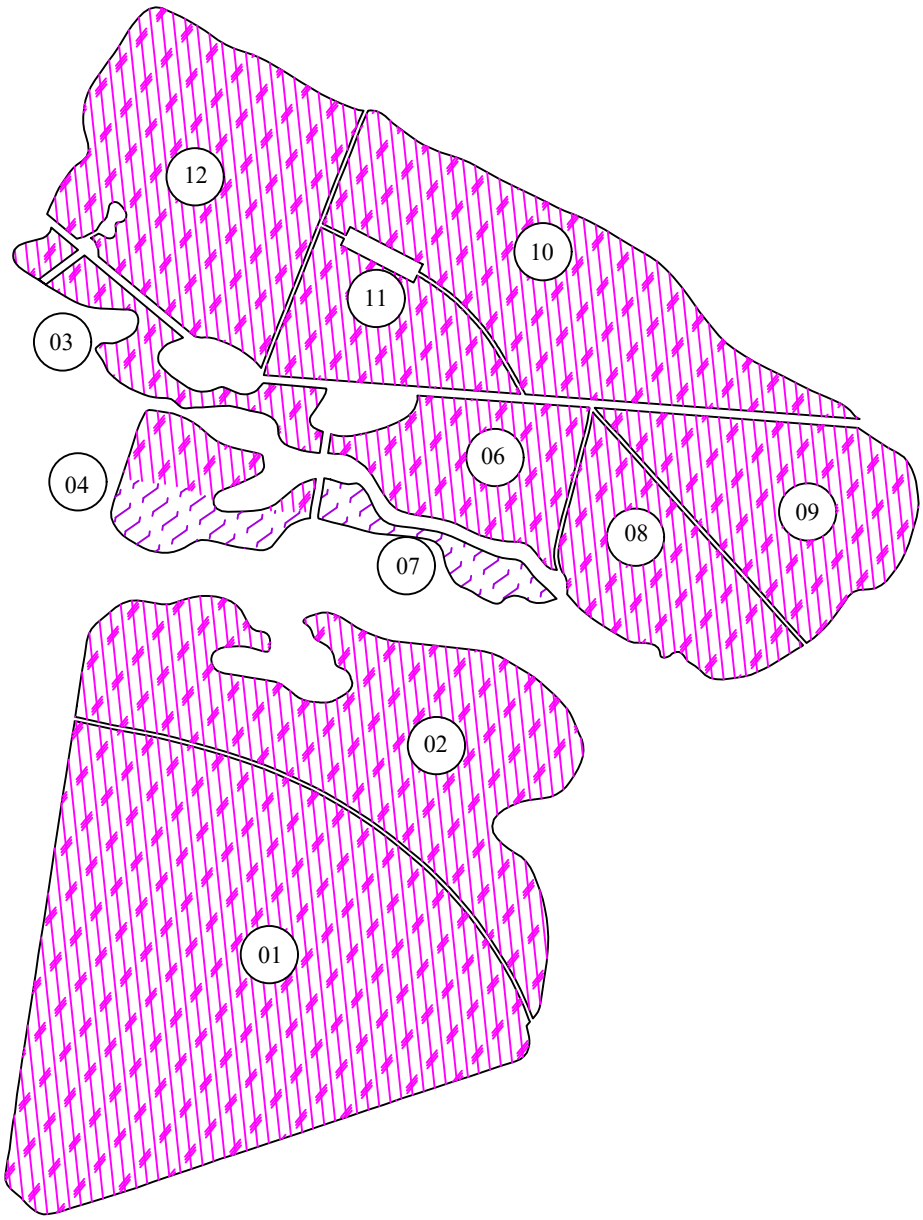

CTC - 9007

CTC -2994

TABELA DE VARIEDADE	
VARIEDADE	ÁREA
CTC2994	76,56
CTC9007	2,33
Total Geral	**78,89**

IPIRANGA AGROINDUSTRIAL

PROJETO: CADERNO DE MAPA 25´26	DATA: 16-07-2025	ESCALA: 1:5000	TOPÓGRAFO: CRISTIAN
FAZENDA: 563 - ESTIVA	MUNICÍPIO: PASSOS - MG		ÁREA (ha): 78,89
PROPRIETÁRIO: ALISON DE SOLZA MACHADO	UNIDADE: IPIRANGA PASSOS S.A.		

Caderno de Mapas

Bloco	Talhao	Variedade	Estágio de Corte	Amb. Prod.	Data Plantio	Último Corte	Área (ha)	Estimativas Área (ha)	Finalid	Produt.	Prod. Total	Dist.	Esp.	Tipo Corte	Experimento
3 · REG 3			**563 · ESTIVA**				**ALISSON DE SOUZA MACHADO**								
1	1	CTC2994	1C	NC	07/03/24	23/05/25	24,57	24,57	1-MO.	125,0	3.071,25	31	1,5	MEC.	
1	2	CTC2994	1C	NC	09/03/24	23/05/25	12,00	12,00	1-MO.	125,0	1.500,00	31	1,5	MEC.	
1	3	CTC2994	1C	NC	23/03/24	23/05/25	1,98	1,98	1-MO.	125,0	247,50	31	1,5	MEC.	
1	4	CTC2994	1C	NC	24/03/24	23/05/25	1,22	1,22	1-MO.	125,0	152,50	31	1,5	MEC.	
1	4	CTC9007	1C	NC	24/03/24	23/05/25	1,28	1,28	1-MO.	125,0	160,00	31	1,5	MEC.	
1	6	CTC2994	1C	NC	24/03/24	23/05/25	3,87	3,87	1-MO.	125,0	483,75	31	1,5	MEC.	
1	7	CTC9007	1C	NC	22/03/24	23/05/25	1,05	1,05	1-MO.	125,0	131,25	31	1,5	MEC.	
1	8	CTC2994	1C	NC	23/03/24	23/05/25	4,63	4,63	1-MO.	125,0	578,75	31	1,5	MEC.	
1	9	CTC2994	1C	NC	23/03/24	23/05/25	6,03	6,03	1-MO.	125,0	753,75	31	1,5	MEC.	
1	10	CTC2994	1C	NC	22/03/24	23/05/25	9,05	9,05	1-MO.	125,0	1.131,25	31	1,5	MEC.	
1	11	CTC2994	1C	NC	21/03/24	23/05/25	3,51	3,51	1-MO.	125,0	438,75	31	1,5	MEC.	
1	12	CTC2994	1C	NC	21/03/24	23/05/25	9,70	9,70	1-MO.	125,0	1.212,50	31	1,5	MEC.	
Total/Média (3 / 563 · ESTIVA)							78,89	78,89		125,0	9.861,25				

N: 7732042.95778454
E: 326122.19517009
LAT: −20°30'9.8230395" (−20.50272862208)
LONG: −46°40'4.0350777" (−46.66778752157)

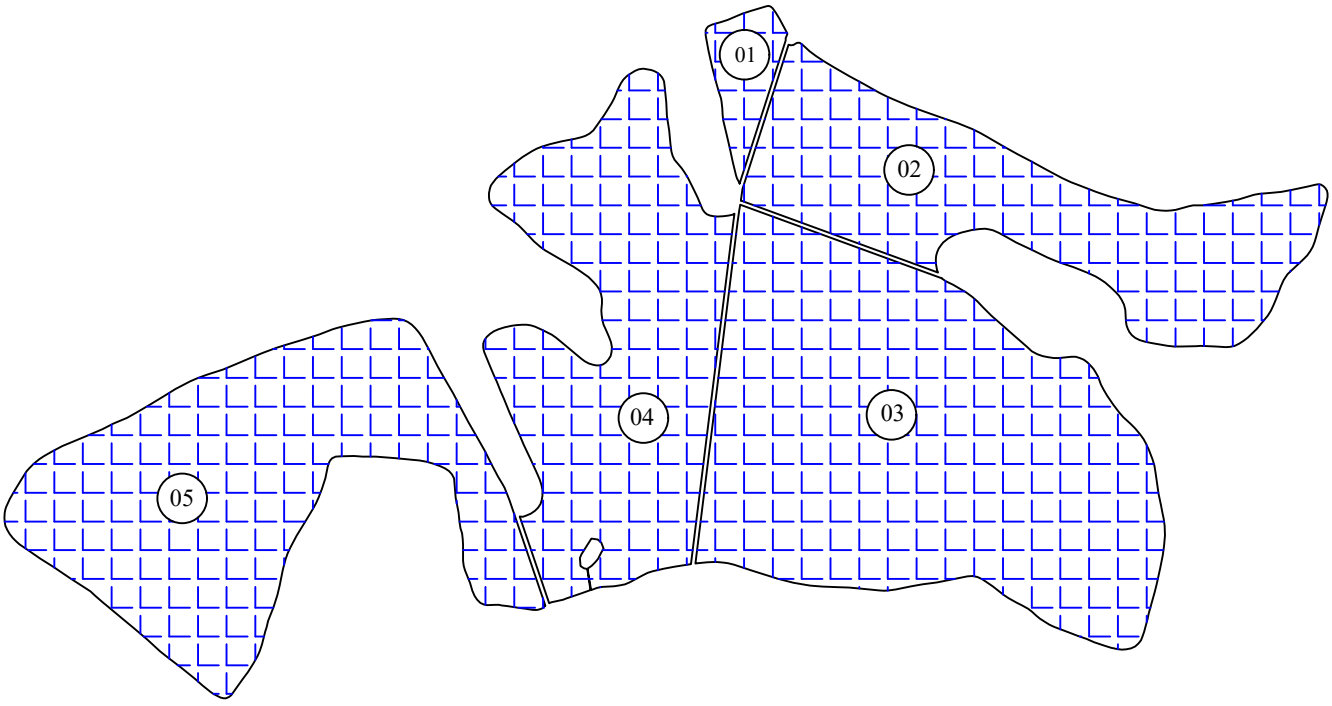

CTC - 2

TABELA DE VARIEDADE	
VARIEDADE	ÁREA
CTC2	56,80
Total Geral	**56,80**

IPIRANGA AGROINDUSTRIAL	PROJETO: CADERNO DE MAPA 25´26	DATA: 16-07-2025	ESCALA: 1:5000	TOPÓGRAFO: CRISTIAN
	FAZENDA: 564 - SÃO SEBASTIÃO II	MUNICÍPIO: PASSOS - MG		ÁREA (ha): 56,80
	PROPRIETÁRIO: IVALDO MAIA RODRIGUES	UNIDADE: IPIRANGA PASSOS S.A.		

Caderno de Mapas

Bloco	Talhao	Variedade	Estágio de Corte	Amb. Prod.	Data Plantio	Último Corte	Área (ha)	Estimativas Área (ha)	Finalid	Produt.	Prod. Total	Dist.	Esp.	Tipo Corte	Experimento
3 · REG 3			**564 · SAO SEB. II**				**IVALDO MAIA RODRIGUES E OUTROS**								
1	1	CTC2	2C	NC	30/09/23	25/04/25	1,14	1,14	1-MO.	120,0	136,80	39	1,5	MEC.	
1	2	CTC2	1C	NC	23/02/24	25/04/25	10,37	10,37	1-MO.	120,0	1.244,40	39	1,5	MEC.	
1	3	CTC2	1C	NC	23/02/24	25/04/25	19,64	19,64	1-MO.	120,0	2.356,80	39	1,5	MEC.	
1	4	CTC2	1C	NC	25/02/24	25/04/25	11,93	11,93	1-MO.	120,0	1.431,60	39	1,5	MEC.	
1	5	CTC2	1C	NC	23/02/24	25/04/25	13,72	13,72	1-MO.	120,0	1.646,40	39	1,5	MEC.	
Total/Média (3 / 564 · SAO SEB. II)							56,80	56,80		120,0	6.816,00				

N: 7713853.634
E: 335030.8915
LAT: −20°40'4.1716" (−20.66782545)
LONG: −46°35'2.6806" (−46.58407794)

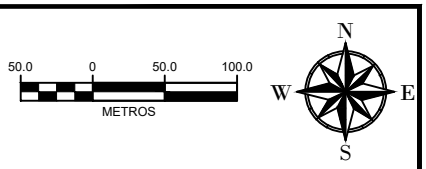

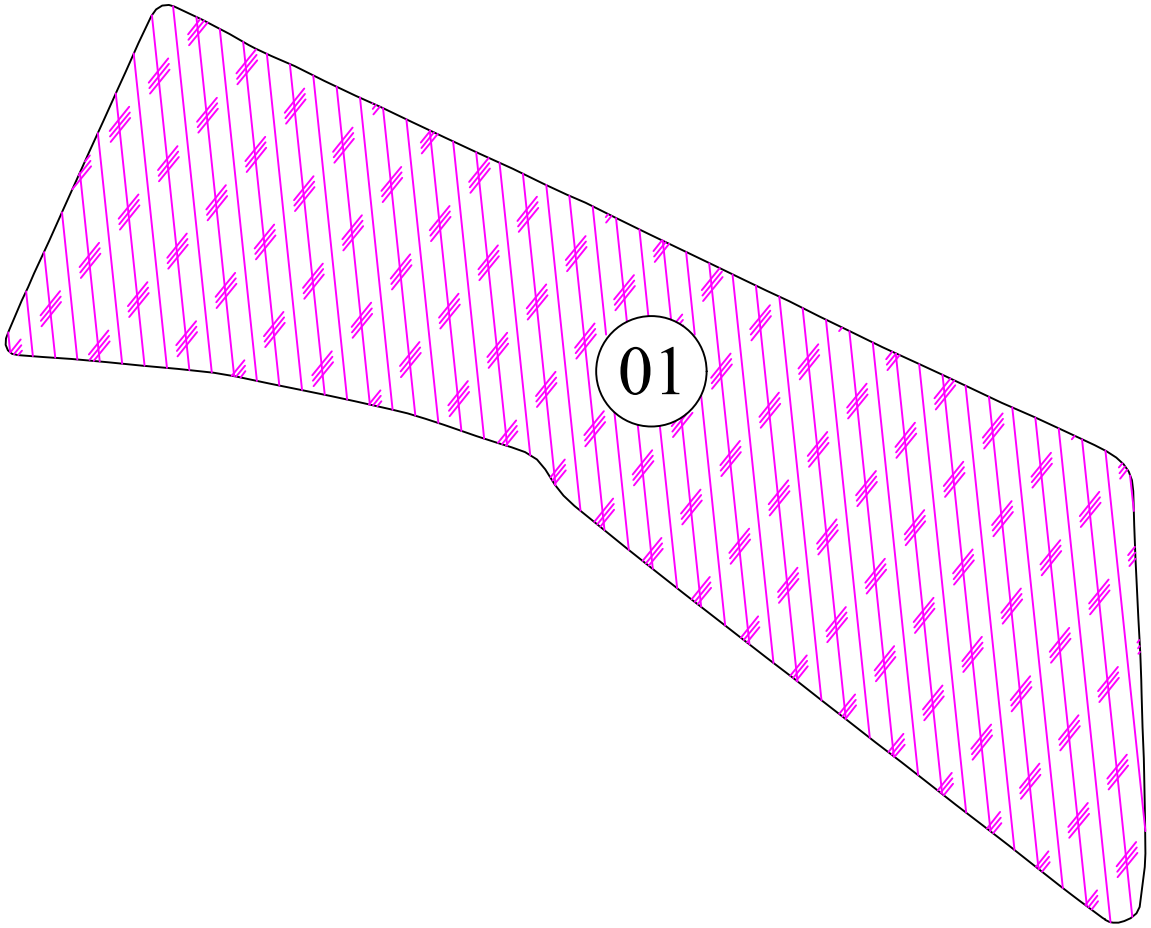

CTC -2994

TABELA DE VARIEDADE	
VARIEDADE	ÁREA
CTC2994	15,24
Total Geral	**15,24**

IPIRANGA AGROINDUSTRIAL	PROJETO: CADERNO DE MAPA 25´26	DATA: 18-07-2025	ESCALA: 1:5000	TOPÓGRAFO: CRISTIAN
	FAZENDA: 565 - SANTO ANTONIO DE PADUA	MUNICÍPIO: PASSOS - MG		ÁREA (ha): 15,24
	PROPRIETÁRIO: OLIVIA NOGUEIRA LEMOS LEAL	UNIDADE: IPIRANGA PASSOS S.A.		

Caderno de Mapas

Bloco	Talhao	Variedade	Estágio de Corte	Amb. Prod.	Data Plantio	Último Corte	Área (ha)	Estimativas Área (ha)	Finalid	Produt.	Prod. Total	Dist.	Esp.	Tipo Corte	Experimento
3 · REG 3			**565 · ST ANT PADUA**				**OLIVIA NOGUEIRA LEMOS LEAL**								
1	1	CTC2994	1C	NC	22/01/24	05/06/25	15,24	15,24	1-MO.	130,0	1.981,20	19	1,5	MEC.	
Total/Média (3 / 565 · ST ANT PADUA)							15,24	15,24		130,0	1.981,20				

N: 7707707.65651955
E: 326194.28773083
LAT: −20°43'21.1323333" (−20.72253675924)
LONG: −46°40'10.1644705" (−46.66949013069)

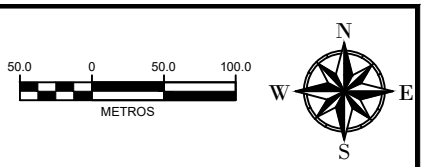

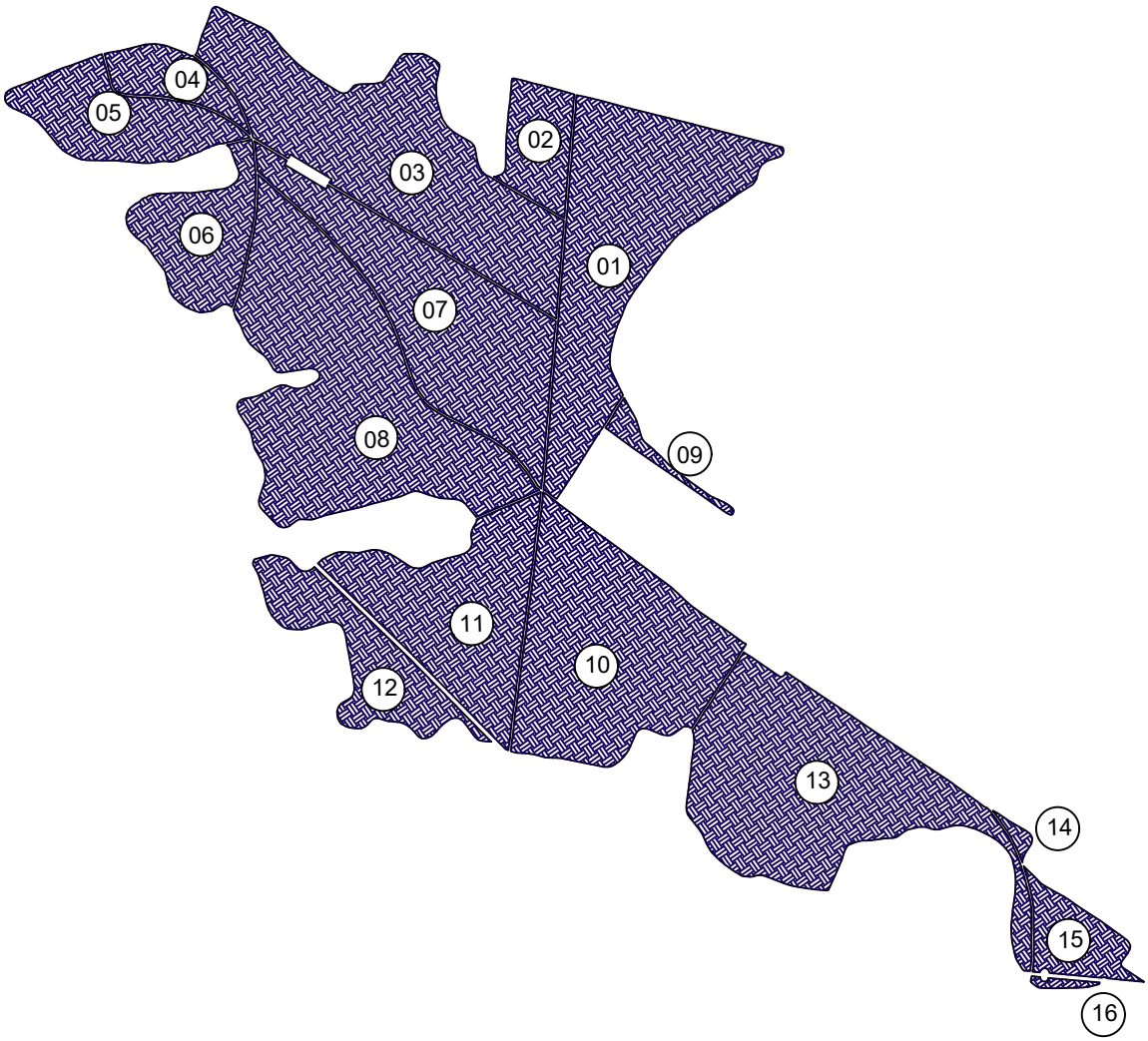

TABELA DE VARIEDADE	
VARIEDADE	ÁREA
CTC9006	139,50
Total Geral	**139,50**

CTC - 9006

IPIRANGA AGROINDUSTRIAL

PROJETO: CADERNO DE MAPA 25´26	DATA: 18-07-2025	ESCALA: 1:5000	TOPÓGRAFO: CRISTIAN
FAZENDA: 566 - TAGUAUNA II	MUNICÍPIO: PASSOS MG		ÁREA (ha): 139,50
PROPRIETÁRIO: MARIA EDUARDA DE SOUZA CAPATO	UNIDADE: IPIRANGA PASSOS		

Caderno de Mapas

Bloco	Talhao	Variedade	Estágio de Corte	Amb. Prod.	Data Plantio	Data Último Corte	Área (ha)	Estimativas Área (ha)	Estimativas Finalid	Estimativas Produt.	Prod. Total	Dist.	Esp.	Tipo Corte	Experimento
3 · REG 3			**566 · TAGUAUNA II**				**MARIA EDUARDA DE SOUZA CAPATO**								
1	1	CTC9006	1C	NC	07/03/24	13/05/25	15,71	15,71	1-MO.	130,0	2.042,30	35	1,5	MEC.	
1	2	CTC9006	1C	NC	14/03/24	13/05/25	3,19	3,19	1-MO.	130,0	414,70	35	1,5	MEC.	
1	3	CTC9006	1C	NC	09/03/24	13/05/25	17,55	17,55	1-MO.	130,0	2.281,50	35	1,5	MEC.	
1	4	CTC9006	1C	NC	18/03/24	13/05/25	2,46	2,46	1-MO.	130,0	319,80	35	1,5	MEC.	
1	5	CTC9006	1C	NC	10/03/24	13/05/25	5,99	5,99	1-MO.	130,0	778,70	35	1,5	MEC.	
1	6	CTC9006	1C	NC	10/03/24	13/05/25	5,28	5,28	1-MO.	130,0	686,40	35	1,5	MEC.	
1	7	CTC9006	1C	NC	08/03/24	13/05/25	13,44	13,44	1-MO.	130,0	1.747,20	35	1,5	MEC.	
1	8	CTC9006	1C	NC	14/03/24	13/05/25	21,25	21,25	1-MO.	130,0	2.762,50	35	1,5	MEC.	
1	9	CTC9006	1C	NC	08/03/24	13/05/25	0,75	0,75	1-MO.	130,0	97,50	35	1,5	MEC.	
1	10	CTC9006	1C	NC	13/03/24	13/05/25	16,25	16,25	1-MO.	130,0	2.112,50	35	1,5	MEC.	
1	11	CTC9006	1C	NC	14/03/24	13/05/25	10,66	10,66	1-MO.	130,0	1.385,80	35	1,5	MEC.	
1	12	CTC9006	1C	NC	14/03/24	13/05/25	5,69	5,69	1-MO.	130,0	739,70	35	1,5	MEC.	
1	13	CTC9006	1C	NC	14/03/24	13/05/25	18,00	18,00	1-MO.	130,0	2.340,00	35	1,5	MEC.	
1	14	CTC9006	1C	NC	15/03/24	13/05/25	0,25	0,25	1-MO.	130,0	32,50	35	1,5	MEC.	
1	15	CTC9006	1C	NC	14/03/24	13/05/25	2,81	2,81	1-MO.	130,0	365,30	35	1,5	MEC.	
1	16	CTC9006	1C	NC	15/03/24	13/05/25	0,22	0,22	1-MO.	130,0	28,60	35	1,5	MEC.	
Total/Média (3 / 566 · TAGUAUNA II)							139,50	139,50		130,0	18.135,00				

N: 7713853.634
E: 335030.8915
LAT: −20°40'4.1716" (−20.66782545)
LONG: −46°35'2.6806" (−46.58407794)

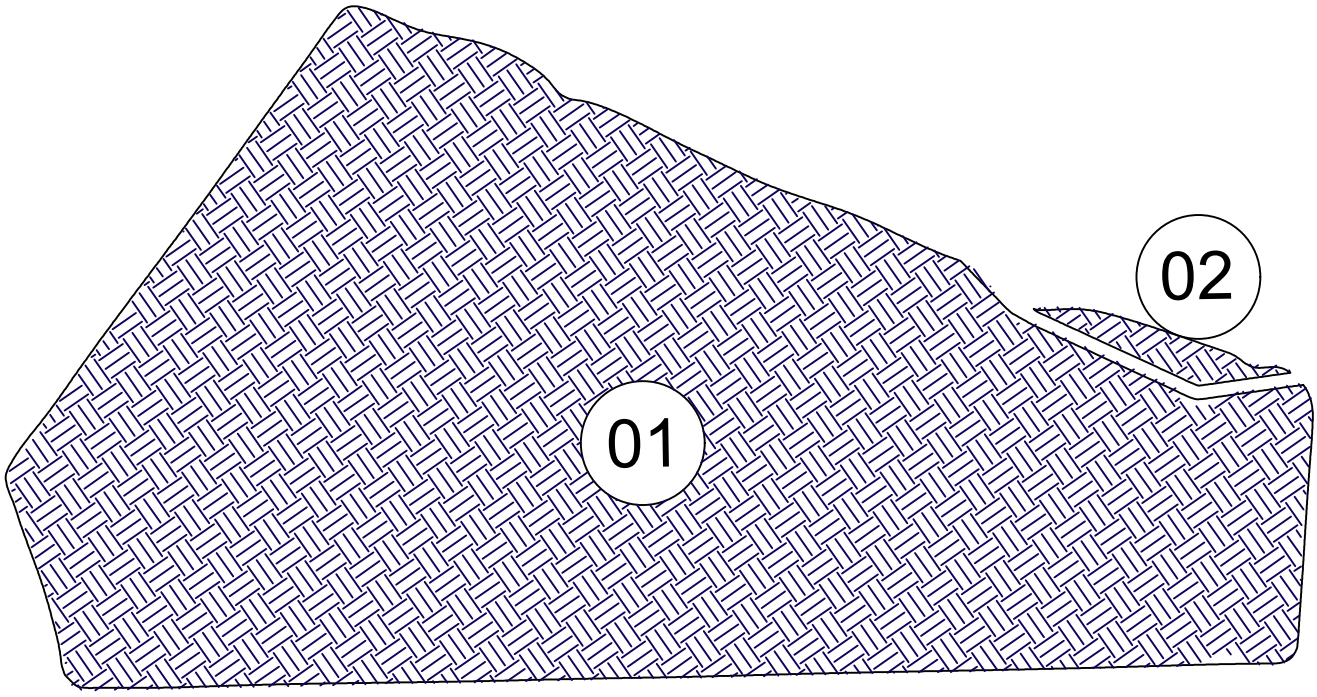

TABELA DE VARIEDADE	
VARIEDADE	ÁREA
CTC9006	31,28
Total Geral	**31,28**

CTC - 9006

IPIRANGA AGROINDUSTRIAL	PROJETO: CADERNO DE MAPA 25´26	DATA: 18-07-2025	ESCALA: 1:5000	TOPÓGRAFO: CRISTIAN
	FAZENDA: 567 - RECANTO FORMOSO	MUNICÍPIO: PASSOS - MG		ÁREA (ha): 31,28
	PROPRIETÁRIO: MARIA EDUARDA DE SOUZA CAPATO	UNIDADE: IPIRANGA PASSOS S.A.		

Caderno de Mapas

Bloco	Talhao	Variedade	Estágio de Corte	Amb. Prod.	Data Plantio	Último Corte	Área (ha)	Estimativas Área (ha)	Finalid	Produt.	Prod. Total	Dist.	Esp.	Tipo Corte	Experimento
3 · REG 3			**567 · REC.FORMOSO**				**MARIA EDUARDA DE SOUZA CAPATO**								
1	1	CTC9006	1C	NC	16/03/24	12/05/25	30,97	30,97	1-MO.	123,0	3.809,31	44,6	1,5	MEC.	
1	2	CTC9006	1C	NC	17/03/24	12/05/25	0,31	0,31	1-MO.	123,0	38,13	44,6	1,5	MEC.	
Total/Média (3 / 567 · REC.FORMOSO)							31,28	31,28		123,0	3.847,44				

N: 7729058.73286770
E: 332810.44748848
LAT: −20°31'49.0373926" (−20.53028816462)
LONG: −46°36'14.2210855" (−46.60395030154)

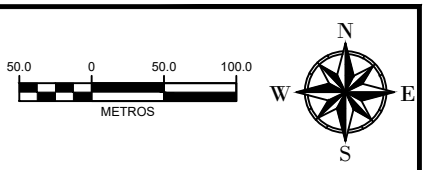

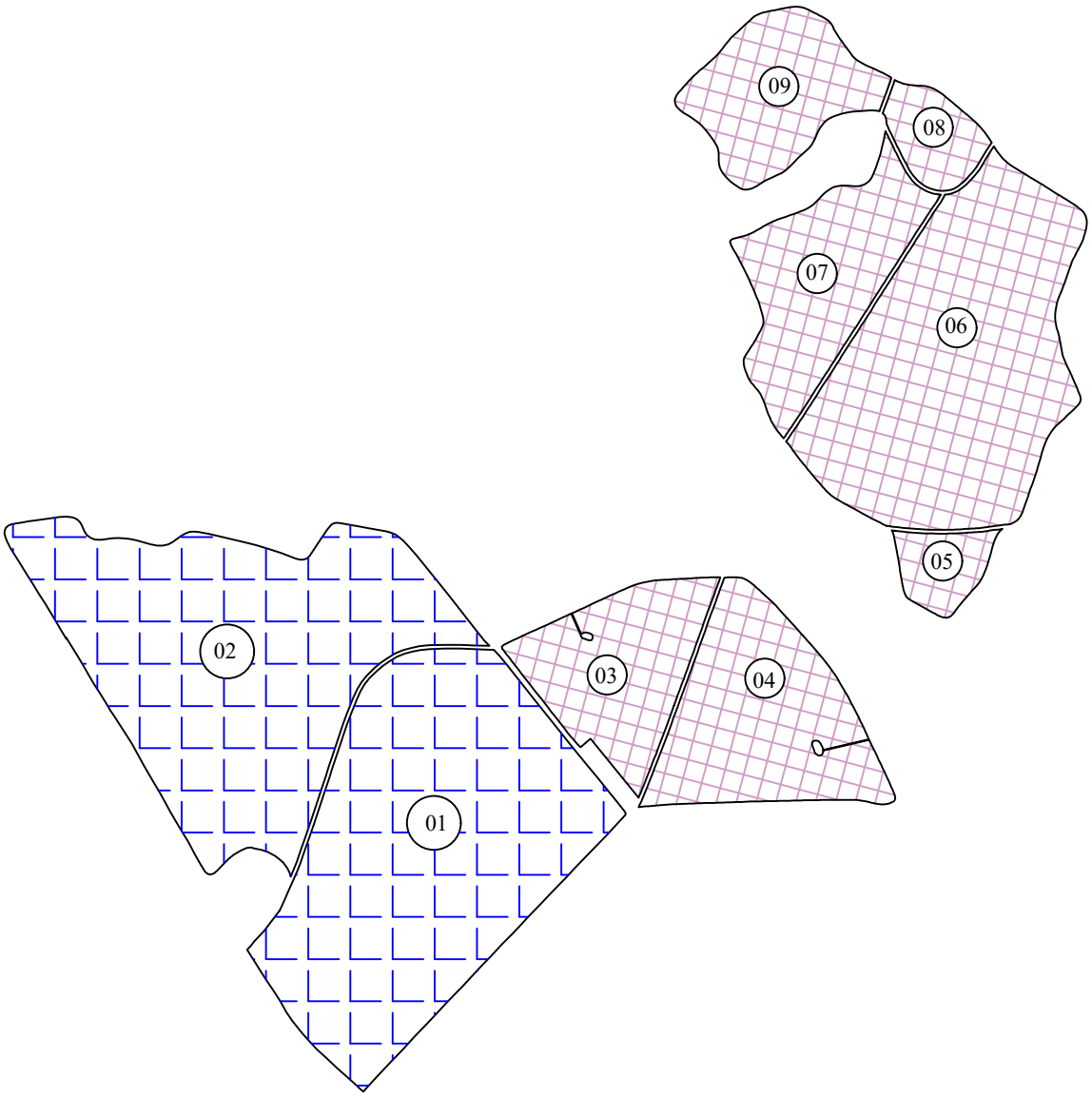

CTC - 2
IAC CTC 07-7207

TABELA DE VARIEDADE	
VARIEDADE	ÁREA
CTC2	30,18
IACCTC07-7207	32,21
Total Geral	**62,39**

IPIRANGA AGROINDUSTRIAL

PROJETO: CADERNO DE MAPA 25´26	DATA: 18-07-2025	ESCALA: 1:5000	TOPÓGRAFO: CRISTIAN
FAZENDA: 568 - JAÚ	MUNICÍPIO: DELFINOPOLIS MG		ÁREA (ha): 62,39
PROPRIETÁRIO: IVALTENIR FRANCISCO M RODRIGUES	UNIDADE: IPIRANGA PASSOS		

Caderno de Mapas

Bloco	Talhao	Variedade	Estágio de Corte	Amb. Prod.	Data Plantio	Último Corte	Área (ha)	Estimativas Área (ha)	Finalid	Produt.	Prod. Total	Dist.	Esp.	Tipo Corte	Experimento
3 · REG 3			**568 · JAU**				**IVALTENIR FRANCISCO MAIA RODRIGUES**								
1	1	CTC2	1C	NC	29/01/24	22/04/25	15,30	15,30	1-MO.	120,0	1.836,00	28	1,5	MEC.	
1	2	CTC2	1C	NC	30/01/24	22/04/25	14,88	14,88	1-MO.	120,0	1.785,60	28	1,5	MEC.	
1	3	CTC9006	FORM	NC	13/02/25		4,10	0,00	.		0,00	28	1,5	N/D	
1	4	CTC9006	FORM	NC	13/02/25		5,75	0,00	.		0,00	28	1,5	N/D	
1	5	IACCTC07-7207	FORM	NC	14/02/25		1,06	0,00	.		0,00	28	1,5	N/D	
1	6	IACCTC07-7207	FORM	NC	14/02/25		11,78	0,00	.		0,00	28	1,5	N/D	
1	7	IACCTC07-7207	FORM	NC	15/02/25		4,56	0,00	.		0,00	28	1,5	N/D	
1	8	IACCTC07-7207	FORM	NC	14/02/25		1,27	0,00	.		0,00	28	1,5	N/D	
1	9	IACCTC07-7207	FORM	NC	15/02/25		3,69	0,00	.		0,00	28	1,5	N/D	
Total/Média (3 / 568 · JAU)							62,39	30,18		120,0	3.621,60				

N: 7713853.634
E: 335030.8915
LAT: −20°40'4.1716" (−20.66782545)
LONG: −46°35'2.6806" (−46.58407794)

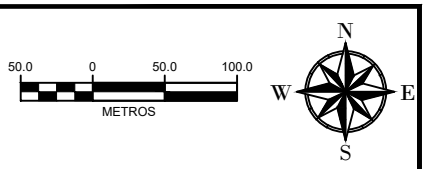

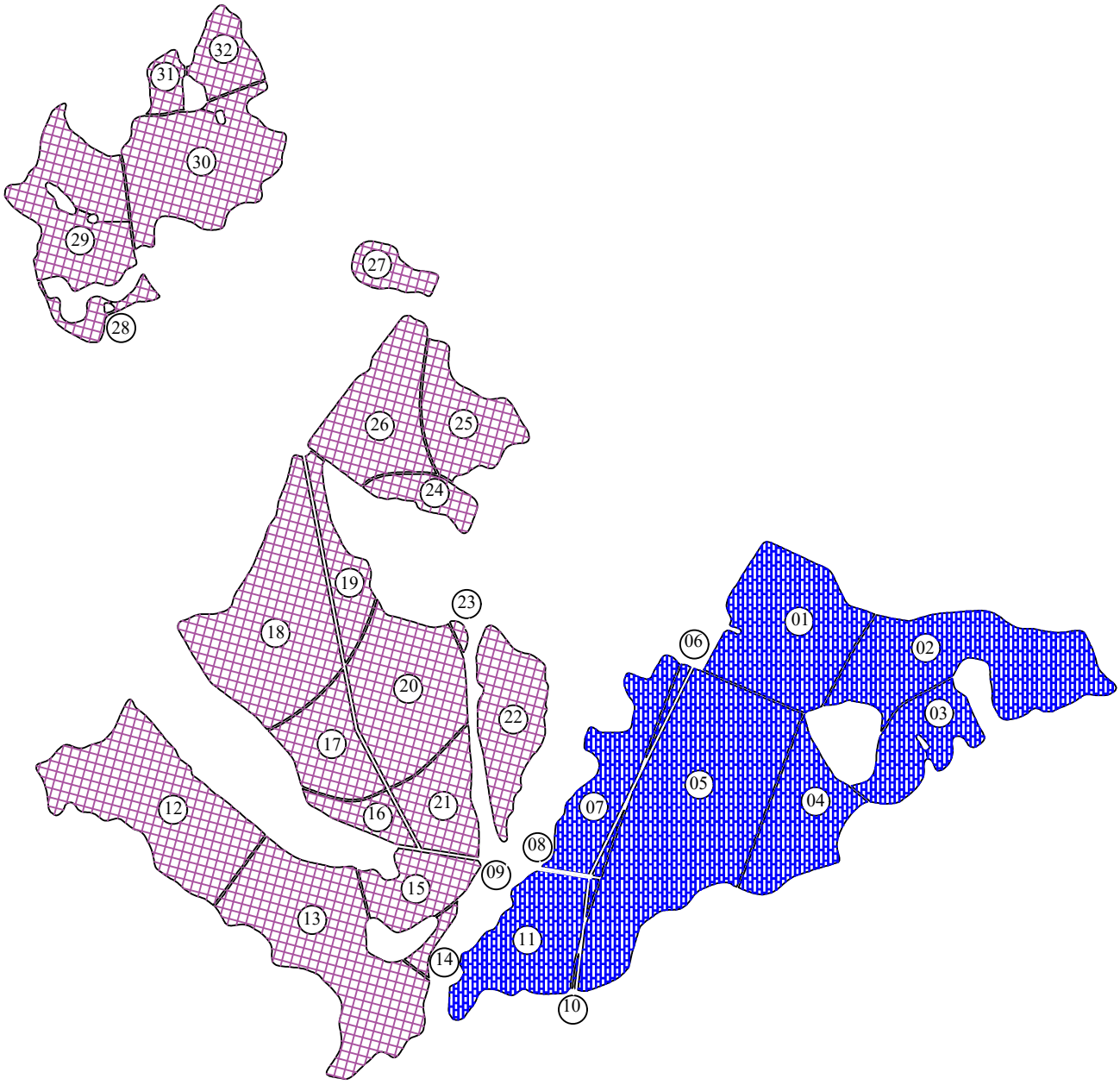

RB 00-5014
IAC CTC 07-8008

TABELA DE VARIEDADE	
VARIEDADE	ÁREA
IACCTC07-8008	141,67
RB005014	85,36
Total Geral	227,03

IPIRANGA AGROINDUSTRIAL

PROJETO: CADERNO DE MAPA 25'26	DATA: 05/06/2024	ESCALA: 1:5000	TOPÓGRAFO: LUIS DUARTE
FAZENDA: 569 - SANTO ANTONIO (LUQUINHA)	MUNICÍPIO: PASSOS - MG		ÁREA (ha): 227,03
PROPRIETÁRIO: 000	UNIDADE: IPIRANGA PASSOS S.A.		

Caderno de Mapas

Bloco	Talhao	Variedade	Estágio de Corte	Amb. Prod.	Data Plantio	Data Último Corte	Área (ha)	Estimativas Área (ha)	Estimativas Finalid	Estimativas Produt.	Prod. Total	Dist.	Esp.	Tipo Corte	Experimento
3 · REG 3			**569 · SANTO ANTONIO**				**PAULO DE ARAUJO RODRIGUES E OUTROS**								
1	1	RB005014	1C	NC	25/01/24	21/05/25	13,33	13,33	1-MO.	135,0	1.799,55	49	1,5	MEC.	
1	2	RB005014	1C	NC	07/02/24	21/05/25	14,92	14,92	1-MO.	135,0	2.014,20	49	1,5	MEC.	
1	3	RB005014	1C	NC	25/01/24	21/05/25	5,93	5,93	1-MO.	135,0	800,55	49	1,5	MEC.	
1	4	RB005014	1C	NC	25/01/24	21/05/25	7,92	7,92	1-MO.	135,0	1.069,20	49	1,5	MEC.	
1	5	RB005014	1C	NC	25/01/24	21/05/25	25,59	25,59	1-MO.	135,0	3.454,65	49	1,5	MEC.	
1	6	RB005014	1C	NC	25/01/24	21/05/25	0,39	0,39	1-MO.	135,0	52,65	49	1,5	MEC.	
1	7	RB005014	1C	NC	25/01/24	21/05/25	7,49	7,49	1-MO.	135,0	1.011,15	49	1,5	MEC.	
1	8	RB005014	1C	NC	25/01/24	21/05/25	0,21	0,21	1-MO.	135,0	28,35	49	1,5	MEC.	
1	9	RB005014	1C	NC	25/01/24	21/05/25	0,10	0,10	1-MO.	135,0	13,50	49	1,5	MEC.	
1	10	RB005014	1C	NC	25/01/24	21/05/25	0,05	0,05	1-MO.	135,0	6,75	49	1,5	MEC.	
1	11	RB005014	1C	NC	25/01/24	21/05/25	9,03	9,03	1-MO.	135,0	1.219,05	49	1,5	MEC.	
1	12	IACCTC07-8008	1C	NC	25/01/24		15,61	15,61	1-MO.	130,0	2.029,30	49	1,5	MEC.	
1	13	IACCTC07-8008	1C	NC	25/01/24	30/07/25	16,95	16,95	1-MO.	130,0	2.203,50	49	1,5	MEC.	
1	14	IACCTC07-8008	1C	NC	25/01/24	30/07/25	0,75	0,75	1-MO.	130,0	97,50	49	1,5	MEC.	
1	15	IACCTC07-8008	1C	NC	25/01/24	30/07/25	4,79	4,79	1-MO.	130,0	622,70	49	1,5	MEC.	
1	16	IACCTC07-8008	1C	NC	25/01/24	18/07/25	2,21	2,21	1-MO.	130,0	287,30	49	1,5	MEC.	
1	17	IACCTC07-8008	1C	NC	25/01/24	18/07/25	5,84	5,84	1-MO.	130,0	759,20	49	1,5	MEC.	
1	18	IACCTC07-8008	1C	NC	25/01/24	18/07/25	16,74	16,74	1-MO.	130,0	2.176,20	49	1,5	MEC.	
1	19	IACCTC07-8008	1C	NC	25/01/24	18/07/25	3,79	3,79	1-MO.	130,0	492,70	49	1,5	MEC.	
1	20	IACCTC07-8008	1C	NC	25/01/24	18/07/25	11,87	11,87	1-MO.	130,0	1.543,10	49	1,5	MEC.	
1	21	IACCTC07-8008	1C	NC	25/01/24	18/07/25	5,26	5,26	1-MO.	130,0	683,80	49	1,5	MEC.	
1	22	IACCTC07-8008	1C	NC	25/01/24	18/07/25	7,57	7,57	1-MO.	130,0	984,10	49	1,5	MEC.	
1	23	IACCTC07-8008	1C	NC	25/01/24	18/07/25	0,21	0,21	1-MO.	130,0	27,30	49	1,5	MEC.	
1	24	IACCTC07-8008	1C	NC	25/01/24	18/07/25	2,56	2,56	1-MO.	130,0	332,80	49	1,5	MEC.	
1	25	IACCTC07-8008	1C	NC	25/01/24	18/07/25	6,38	6,38	1-MO.	130,0	829,40	49	1,5	MEC.	
1	26	IACCTC07-8008	1C	NC	25/01/24	18/07/25	9,35	9,35	1-MO.	130,0	1.215,50	49	1,5	MEC.	
1	27	IACCTC07-8008	1C	NC	25/01/24	18/07/25	2,18	2,18	1-MO.	130,0	283,40	49	1,5	MEC.	
1	28	IACCTC07-8008	1C	NC	25/01/24	30/07/25	1,70	1,70	1-MO.	130,0	221,00	49	1,5	MEC.	
1	29	IACCTC07-8008	1C	NC	25/01/24	30/07/25	10,68	10,68	1-MO.	130,0	1.388,40	49	1,5	MEC.	
1	30	IACCTC07-8008	1C	NC	25/01/24	30/07/25	12,90	12,90	1-MO.	130,0	1.677,00	49	1,5	MEC.	
1	31	IACCTC07-8008	1C	NC	25/01/24	30/07/25	4,90	4,90	1-MO.	130,0	637,00	49	1,5	MEC.	
Total/Média (3 / 569 · SANTO ANTONIO)							227,20	227,20		131,9	29.960,80				

N: 7733449.65785052
E: 332098.31974292
LAT: −20°29'26.0285984" (−20.49056349955)
LONG: −46°36'37.3097355" (−46.61036381542)

50.0 0 50.0 100.0
METROS

N W E S

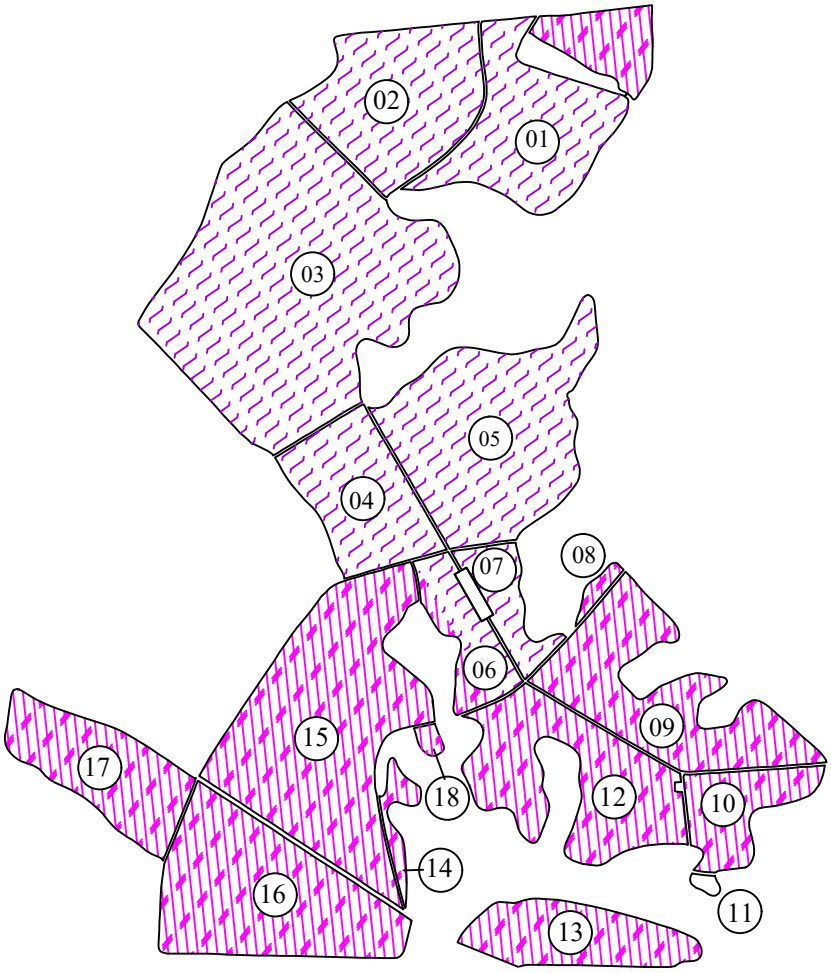

CTC -2994

CTC - 9007

TABELA DE VARIEDADE	
VARIEDADE	ÁREA
CTC2994	53,99
CTC9007	54,42
Total Geral	**108,41**

IPIRANGA AGROINDUSTRIAL

PROJETO: CADERNO DE MAPA 25´26	DATA: 18-07-2025	ESCALA: 1:5000	TOPÓGRAFO: CRISTIAN
FAZENDA: 570 - SANTA TEREZINHA	MUNICÍPIO: PASSOS - MG		ÁREA (ha): 108,41
PROPRIETÁRIO: MARCO ANDRADE LEMOS	UNIDADE: IPIRANGA PASSOS S.A.		

Caderno de Mapas

Bloco	Talhao	Variedade	Estágio de Corte	Amb. Prod.	Data Plantio	Data Último Corte	Área (ha)	Estimativas Área (ha)	Estimativas Finalid	Estimativas Produt.	Prod. Total	Dist.	Esp.	Tipo Corte	Experimento
3 · REG 3			**570 · SANTA TEREZINHA**				**MARCO ANDRADE LEMOS**								
1	1	CTC2994	1C	NC	13/03/24	25/04/25	2,29	2,29	1-MO.	115,0	263,35	31	1,5	MEC.	
1	1	CTC9007	1C	NC	13/03/24	25/04/25	6,73	6,73	1-MO.	115,0	773,95	31	1,5	MEC.	
1	2	CTC9007	1C	NC	01/03/24	25/04/25	7,30	7,30	1-MO.	115,0	839,50	31	1,5	MEC.	
1	3	CTC9007	1C	NC	28/02/24	25/04/25	20,79	20,79	1-MO.	115,0	2.390,85	31	1,5	MEC.	
1	4	CTC9007	1C	NC	01/03/24	25/04/25	5,21	5,21	1-MO.	115,0	599,15	31	1,5	MEC.	
1	5	CTC9007	1C	NC	29/02/24	25/04/25	10,92	10,92	1-MO.	115,0	1.255,80	31	1,5	MEC.	
1	6	CTC2994	1C	NC	24/03/24	25/04/25	0,88	0,88	1-MO.	115,0	101,20	31	1,5	MEC.	
1	6	CTC9007	1C	NC	24/03/24	25/04/25	1,64	1,64	1-MO.	115,0	188,60	31	1,5	MEC.	
1	7	CTC9007	1C	NC	29/02/24	25/04/25	1,83	1,83	1-MO.	115,0	210,45	31	1,5	MEC.	
1	8	CTC2994	1C	NC	12/04/24	25/04/25	0,31	0,31	1-MO.	115,0	35,65	31	1,5	MEC.	
1	9	CTC2994	1C	NC	14/04/24	25/04/25	7,49	7,49	1-MO.	115,0	861,35	31	1,5	MEC.	
1	10	CTC2994	1C	NC	13/04/24	25/04/25	2,83	2,83	1-MO.	115,0	325,45	31	1,5	MEC.	
1	11	CTC2994	1C	NC	13/04/24	25/04/25	0,15	0,15	1-MO.	115,0	17,25	31	1,5	MEC.	
1	12	CTC2994	1C	NC	11/04/24	25/04/25	7,34	7,34	1-MO.	115,0	844,10	31	1,5	MEC.	
1	13	CTC2994	1C	NC	17/04/24	25/04/25	4,10	4,10	1-MO.	115,0	471,50	31	1,5	MEC.	
1	14	CTC2994	1C	NC	10/04/24	25/04/25	0,71	0,71	1-MO.	115,0	81,65	31	1,5	MEC.	
1	15	CTC2994	1C	NC	13/04/24	25/04/25	13,34	13,34	1-MO.	115,0	1.534,10	31	1,5	MEC.	
1	16	CTC2994	1C	NC	14/04/24	25/04/25	9,27	9,27	1-MO.	115,0	1.066,05	31	1,5	MEC.	
1	17	CTC2994	1C	NC	15/04/24	25/04/25	5,07	5,07	1-MO.	115,0	583,05	31	1,5	MEC.	
1	18	CTC2994	1C	NC	10/04/24	25/04/25	0,21	0,21	1-MO.	115,0	24,15	31	1,5	MEC.	
Total/Média (3 / 570 · SANTA TEREZINHA)							108,41	108,41		115,0	12.467,15				

N: 7713853.634
E: 335030.8915
LAT: −20°40'4.1716" (−20.66782545)
LONG: −46°35'2.6806" (−46.58407794)

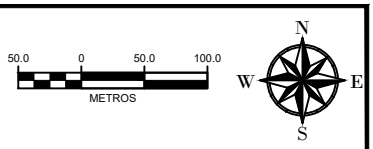

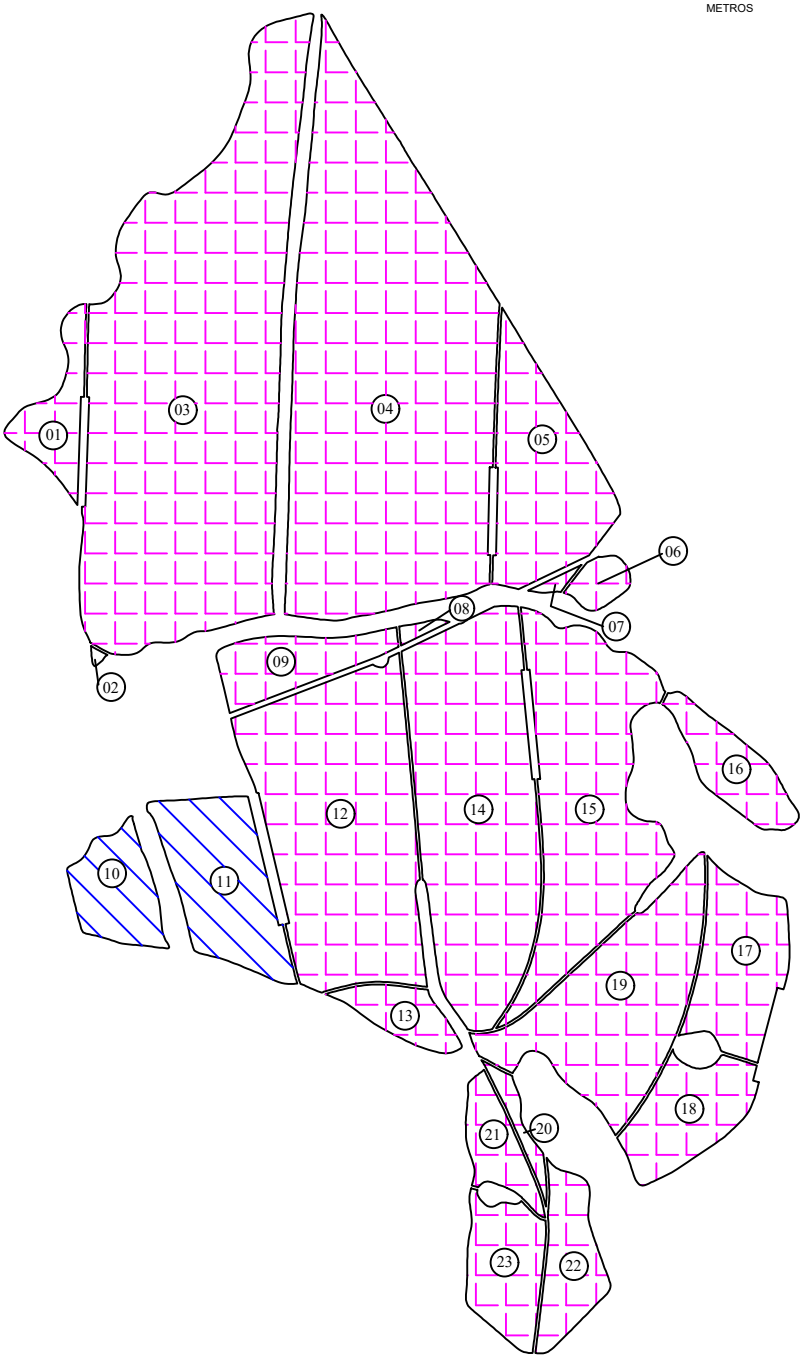

RB 96-6928
RB 85-5156

TABELA DE VARIEDADE	
VARIEDADE	Soma de Área Líquida
RB 96-6928	144,49
RB 85-5156	8,14
Total Geral	152,63

IPIRANGA AGROINDUSTRIAL

PROJETO: CADERNO DE MAPA 25'26	DATA: 22/04/2025	ESCALA: 1:5000	TOPÓGRAFO: CRISTIAN
FAZENDA: 571 - SALGADEIRA	MUNICÍPIO: DELFINÓPOLIS		ÁREA (ha): 152,63
PROPRIETÁRIO: JOSÉ PINTO E THAIMARA PINTO	UNIDADE: IPIRANGA PASSOS S.A.		

Caderno de Mapas

Bloco	Talhao	Variedade	Estágio de Corte	Amb. Prod.	Data Plantio	Data Último Corte	Área (ha)	Estimativas Área (ha)	Estimativas Finalid	Estimativas Produt.	Prod. Total	Dist.	Esp.	Tipo Corte	Experimento
3 · REG 3			**571 · SALGADEIRA**					**PAULO DE ARAUJO RODRIGUES E OUTROS**							
1	1	RB966928	FORM	IN	27/02/25		2,14	0,00	.		0,00	47	1,5	N/D	
1	2	RB966928	FORM	IN	27/02/25		0,05	0,00	.		0,00	47	1,5	N/D	
1	3	RB966928	FORM	IN	01/03/25		31,19	0,00	.		0,00	47	1,5	N/D	
1	4	RB966928	FORM	IN	02/03/25		30,22	0,00	.		0,00	47	1,5	N/D	
1	5	RB966928	FORM	IN	01/03/25		6,72	0,00	.		0,00	47	1,5	N/D	
1	6	RB966928	FORM	IN	01/03/25		0,79	0,00	.		0,00	47	1,5	N/D	
1	7	RB966928	FORM	IN	01/03/25		0,15	0,00	.		0,00	47	1,5	N/D	
1	8	RB966928	FORM	IN	03/03/25		0,19	0,00	.		0,00	47	1,5	N/D	
1	9	RB966928	FORM	IN	03/03/25		2,66	0,00	.		0,00	47	1,5	N/D	
1	10	RB855156	FORM	IN	24/01/25		2,75	0,00	.		0,00	47	1,5	N/D	
1	11	RB855156	FORM	IN	25/01/25		5,39	0,00	.		0,00	47	1,5	N/D	
1	12	RB966928	FORM	IN	02/03/25		14,85	0,00	.		0,00	47	1,5	N/D	
1	13	RB966928	FORM	IN	03/03/25		1,59	0,00	.		0,00	47	1,5	N/D	
1	14	RB966928	FORM	IN	04/03/25		14,47	0,00	.		0,00	47	1,5	N/D	
1	15	RB966928	FORM	IN	05/03/25		11,82	0,00	.		0,00	47	1,5	N/D	
1	16	RB966928	FORM	IN	05/03/25		2,52	0,00	.		0,00	47	1,5	N/D	
1	17	RB966928	FORM	IN	05/03/25		4,55	0,00	.		0,00	47	1,5	N/D	
1	18	RB966928	FORM	IN	05/03/25		3,56	0,00	.		0,00	47	1,5	N/D	
1	19	RB966928	FORM	IN	05/03/25		8,80	0,00	.		0,00	47	1,5	N/D	
1	20	RB966928	FORM	IN	29/01/25		0,60	0,00	.		0,00	47	1,5	N/D	
1	21	RB966928	FORM	IN	29/01/25		1,76	0,00	.		0,00	47	1,5	N/D	
1	22	RB966928	FORM	IN	28/01/25		2,72	0,00	.		0,00	47	1,5	N/D	
1	23	RB966928	FORM	IN	25/01/25		3,14	0,00	.		0,00	47	1,5	N/D	
Total/Média (3 / 571 · SALGADEIRA)							152,63	0,00			0,00				

N: 7713853.634
E: 335030.8915
LAT: −20°40'4.1716" (−20.66782545)
LONG: −46°35'2.6806" (−46.58407794)

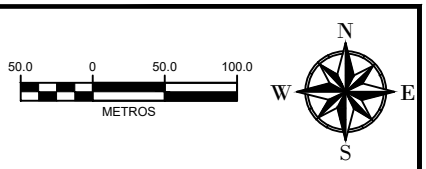

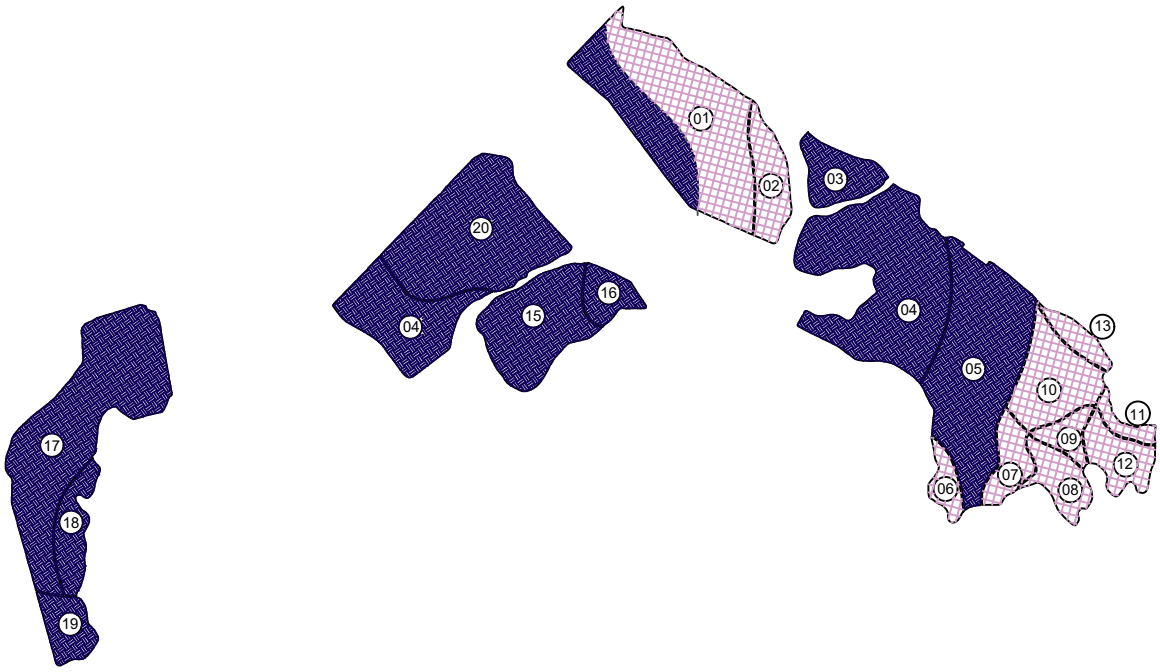

CTC - 9006

IAC CTC 07-7207

TABELA DE VARIEDADE	
VARIEDADE	ÁREA
CTC9006	104,12
CTC9007	7,02
IACCTC07-7207	40,28
Total Geral	**151,42**

IPIRANGA AGROINDUSTRIAL

PROJETO: CADERNO DE MAPA 25´26	DATA: 21-07-2025	ESCALA: 1:5000	TOPÓGRAFO: CRISTIAN
FAZENDA: 572 - SANTA MARIA III	MUNICÍPIO: PASSOS - MG		ÁREA (ha): 151,42
PROPRIETÁRIO:	UNIDADE: IPIRANGA PASSOS S.A.		

Caderno de Mapas

Bloco	Talhao	Variedade	Estágio de Corte	Amb. Prod.	Data Plantio	Data Último Corte	Área (ha)	Estimativas Área (ha)	Estimativas Finalid	Estimativas Produt.	Prod. Total	Dist.	Esp.	Tipo Corte	Experimento
3 · REG 3			**572 · SANTA MARIA III**				**JOSE IVALDO RODRIGUES NETO E OUTRO(S)**								
1	1	CTC9007	1C	NC	27/03/24	09/05/25	7,02	7,02	1-MO.	120,0	842,40	42	1,5	MEC.	
1	1	IACCTC07-7207	1C	NC	27/03/24	09/05/25	14,25	14,25	1-MO.	120,0	1.710,00	42	1,5	MEC.	
1	2	IACCTC07-7207	1C	NC	06/04/24	09/05/25	3,98	3,98	1-MO.	120,0	477,60	42	1,5	MEC.	
1	3	CTC9006	1C	NC	27/03/24	09/05/25	3,90	3,90	1-MO.	120,0	468,00	42	1,5	MEC.	
1	4	CTC9006	1C	NC	17/03/24	09/05/25	19,58	19,58	1-MO.	120,0	2.349,60	42	1,5	MEC.	
1	5	CTC9006	1C	NC	18/03/24	09/05/25	17,47	17,47	1-MO.	120,0	2.096,40	42	1,5	MEC.	
1	6	IACCTC07-7207	1C	NC	09/04/24	09/05/25	1,66	1,66	1-MO.	120,0	199,20	42	1,5	MEC.	
1	7	IACCTC07-7207	1C	NC	08/04/24	09/05/25	2,78	2,78	1-MO.	120,0	333,60	42	1,5	MEC.	
1	8	IACCTC07-7207	1C	NC	09/04/24	09/05/25	3,10	3,10	1-MO.	120,0	372,00	42	1,5	MEC.	
1	9	IACCTC07-7207	1C	NC	08/04/24	09/05/25	1,75	1,75	1-MO.	120,0	210,00	42	1,5	MEC.	
1	10	IACCTC07-7207	1C	NC	08/04/24	09/05/25	6,55	6,55	1-MO.	120,0	786,00	42	1,5	MEC.	
1	11	IACCTC07-7207	1C	NC	09/04/24	09/05/25	1,10	1,10	1-MO.	120,0	132,00	42	1,5	MEC.	
1	12	IACCTC07-7207	1C	NC	10/04/24	09/05/25	3,48	3,48	1-MO.	120,0	417,60	42	1,5	MEC.	
1	13	IACCTC07-7207	1C	NC	08/04/24	09/05/25	1,63	1,63	1-MO.	120,0	195,60	42	1,5	MEC.	
1	14	CTC9006	FORM	NC	21/02/25		8,30	0,00	.		0,00	42	1,5	N/D	
1	15	CTC9006	FORM	NC	25/02/25		9,47	0,00	.		0,00	42	1,5	N/D	
1	16	CTC9006	FORM	NC	24/02/25		2,46	0,00	.		0,00	42	1,5	N/D	
1	17	CTC9006	FORM	NC	13/02/25		19,62	0,00	.		0,00	42	1,5	N/D	
1	18	CTC9006	FORM	NC	11/02/25		3,46	0,00	.		0,00	42	1,5	N/D	
1	19	CTC9006	FORM	NC	11/02/25		2,97	0,00	.		0,00	42	1,5	N/D	
1	20	CTC9006	FORM	NC	19/02/25		16,89	0,00	.		0,00	42	1,5	N/D	
Total/Média (3 / 572 · SANTA MARIA III)							151,42	88,25		120,0	10.590,00				

N: 7707117.47183689
E: 326184.94735916
LAT: −20°43'40.3193523" (−20.72786648676)
LONG: −46°40'10.6976843" (−46.66963824565)

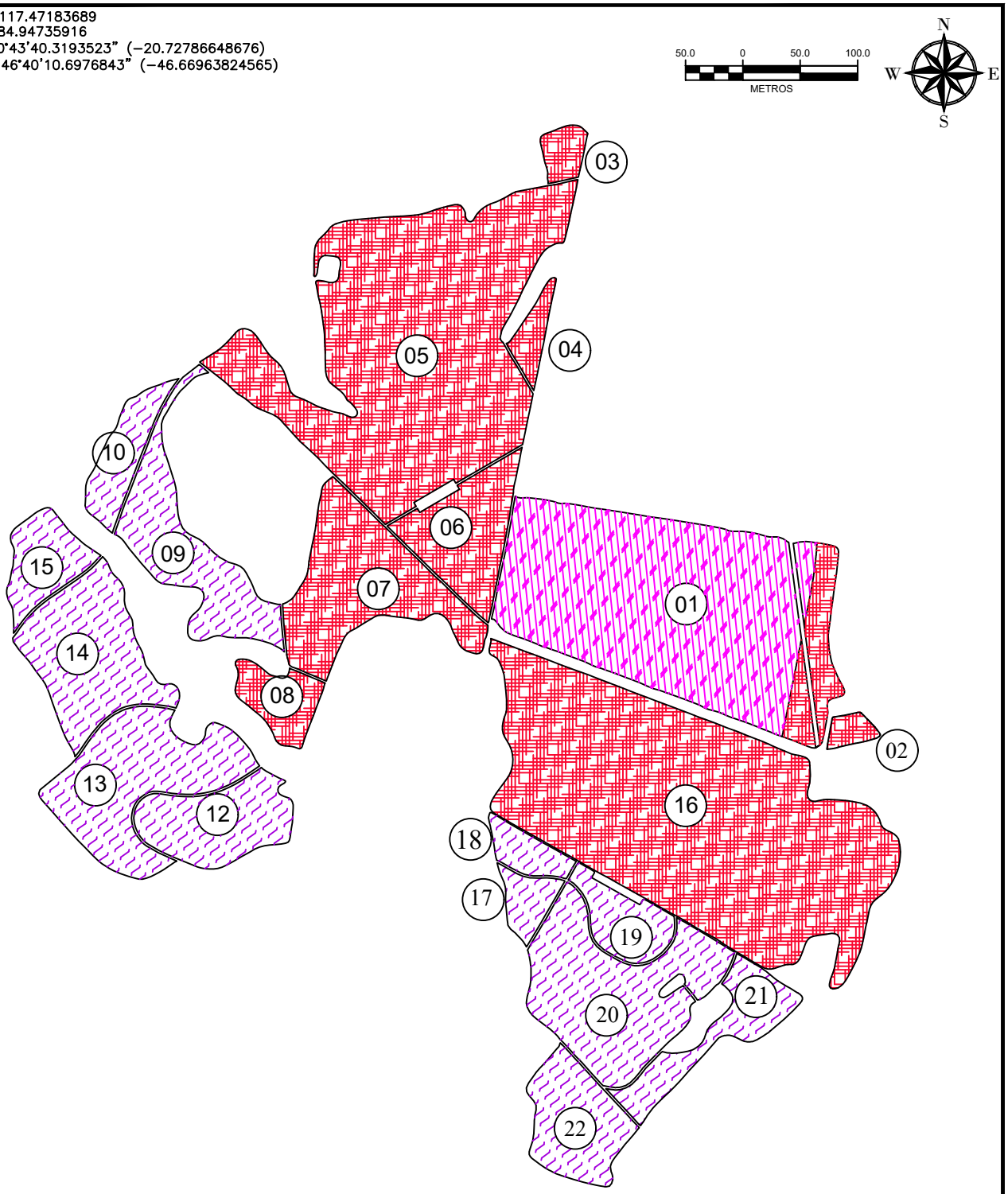

CTC -2994
CTC - 9007
IAC SP 01-5503

TABELA DE VARIEDADE	
VARIEDADE	ÁREA
CTC2994	23,65
CTC9007	55,21
IACSP01-5503	84,62
Total Geral	**163,48**

IPIRANGA AGROINDUSTRIAL

PROJETO: CADERNO DE MAPA 25´26	DATA: 21-07-2025	ESCALA: 1:5000	TOPÓGRAFO: LUÍS DUARTE
FAZENDA: 573 - ENGENHO DE SERRA	MUNICÍPIO: PASSOS - MG		ÁREA (ha): 163,48
PROPRIETÁRIO: VALDIR VASCONCELO DA SILVA	UNIDADE: IPIRANGA PASSOS S.A.		

Caderno de Mapas

Bloco	Talhao	Variedade	Estágio de Corte	Amb. Prod.	Data Plantio	Último Corte	Área (ha)	Estimativas Área (ha)	Finalid	Produt.	Prod. Total	Dist.	Esp.	Tipo Corte	Experimento
3 · REG 3			**573 · ENG. DE SERRA**				**VALDIR VASCONCELOS DA SILVA**								
1	1	CTC2994	2C	NC	10/03/24	11/07/25	23,65	23,65	1-MO.	120,0	2.838,00	30	1,5	MEC.	
1	1	IACSP01-5503	2C	NC	10/03/24	11/07/25	2,75	2,75	1-MO.	120,0	330,00	30	1,5	MEC.	
1	2	IACSP01-5503	FORM	NC	20/12/24		0,60	0,00	.		0,00	30	1,5	N/D	
1	3	IACSP01-5503	1C	NC	20/04/24	11/07/25	0,95	0,95	1-MO.	120,0	114,00	30	1,5	MEC.	
1	4	IACSP01-5503	1C	NC	20/04/24	11/07/25	1,02	1,02	1-MO.	120,0	122,40	30	1,5	MEC.	
1	5	IACSP01-5503	1C	NC	10/04/24	11/07/25	29,43	29,43	1-MO.	120,0	3.531,60	30	1,5	MEC.	
1	6	IACSP01-5503	1C	NC	10/04/24	11/07/25	4,93	4,93	1-MO.	120,0	591,60	30	1,5	MEC.	
1	7	IACSP01-5503	1C	NC	10/04/24	11/07/25	8,39	8,39	1-MO.	120,0	1.006,80	30	1,5	MEC.	
1	8	IACSP01-5503	1C	NC	09/04/24	11/07/25	2,18	2,18	1-MO.	120,0	261,60	30	1,5	MEC.	
1	9	CTC9007	1C	NC	09/04/24	11/07/25	6,29	6,29	1-MO.	120,0	754,80	30	1,5	MEC.	
1	10	CTC9007	2C	NC	09/04/24	11/07/25	2,45	2,45	1-MO.	120,0	294,00	30	1,5	MEC.	
1	12	CTC9007	1C	NC	09/04/24	11/07/25	4,83	4,83	1-MO.	120,0	579,60	30	1,5	MEC.	
1	13	CTC9007	1C	NC	09/04/24	11/07/25	8,49	8,49	1-MO.	120,0	1.018,80	30	1,5	MEC.	
1	14	CTC9007	1C	NC	09/04/24	11/07/25	7,25	7,25	1-MO.	120,0	870,00	30	1,5	MEC.	
1	15	CTC9007	2C	NC	08/04/24	11/07/25	2,76	2,76	1-MO.	120,0	331,20	30	1,5	MEC.	
1	16	IACSP01-5503	1C	NC	11/04/24	11/07/25	34,37	34,37	1-MO.	120,0	4.124,40	30	1,5	MEC.	
1	17	CTC9007	FORM	NC	13/12/24		1,29	0,00	.		0,00	30	1,5	N/D	
1	18	CTC9007	FORM	NC	13/12/24		1,34	0,00	.		0,00	30	1,5	N/D	
1	19	CTC9007	FORM	NC	15/12/24		2,48	0,00	.		0,00	30	1,5	N/D	
1	20	CTC9007	FORM	NC	17/12/24		9,96	0,00	.		0,00	30	1,5	N/D	
1	21	CTC9007	FORM	NC	18/12/24		3,54	0,00	.		0,00	30	1,5	N/D	
1	22	CTC9007	FORM	NC	19/12/24		4,53	0,00	.		0,00	30	1,5	N/D	
Total/Média (3 / 573 · ENG. DE SERRA)							163,48	139,74		120,0	16.768,80				

N: 7732643.43161309
E: 330376.93223693
LAT: -20°29'51.6910429" (-20.49769195636)
LONG: -46°37'36.9905488" (-46.62694181911)

50.0 0 50.0 100.0
METROS

N
W E
S

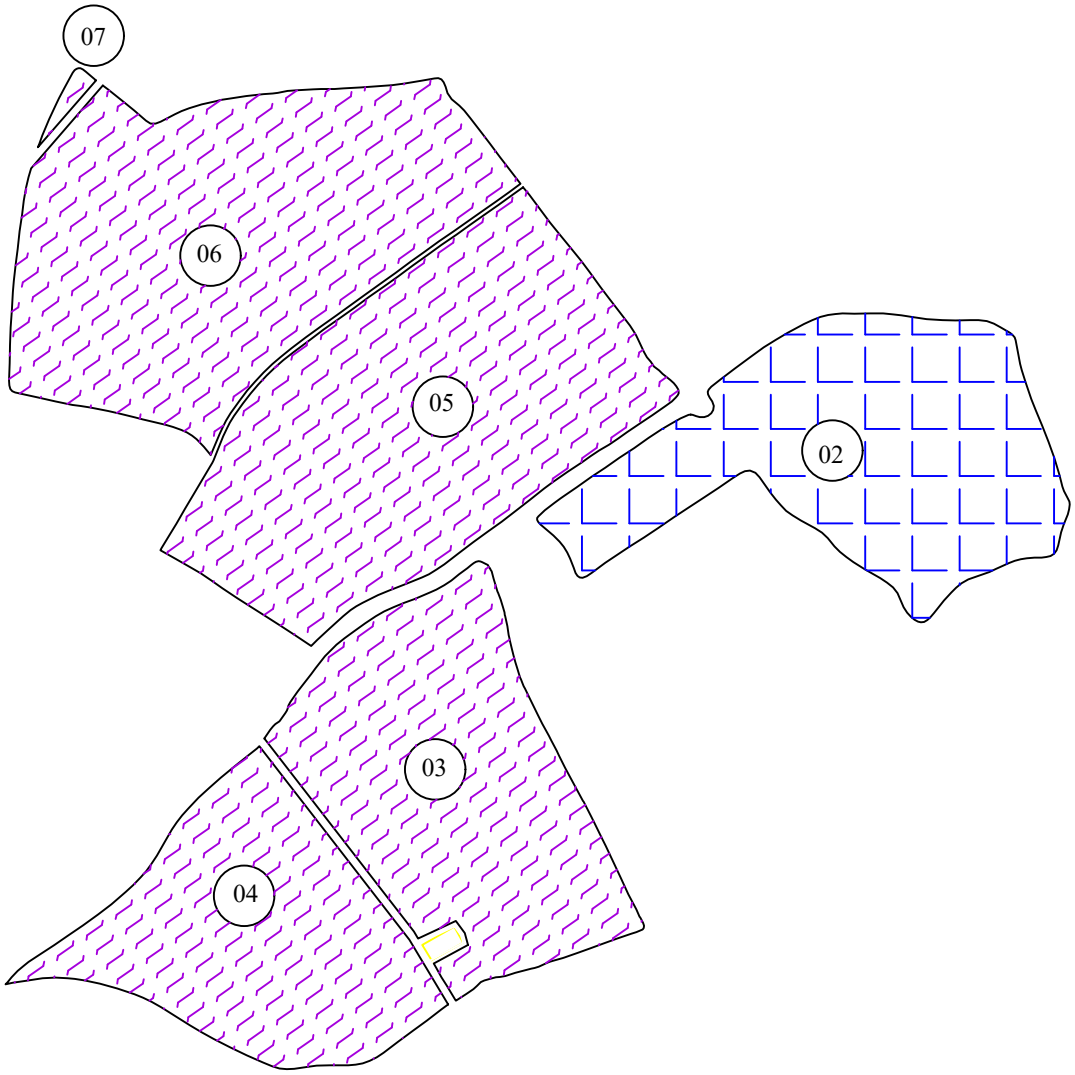

CTC - 2
CTC - 9007

TABELA DE VARIEDADE	
VARIEDADE	ÁREA
CTC2	11,90
CTC9007	52,75
Total Geral	**64,65**

IPIRANGA AGROINDUSTRIAL

PROJETO: CADERNO DE MAPA 25´26	DATA: 21-07-2025	ESCALA: 1:5000	TOPÓGRAFO: CRISTIAN
FAZENDA: 574 - SÃO SEBASTIÃO III	MUNICÍPIO: PASSOS - MG		ÁREA (ha): 64,65
PROPRIETÁRIO: IVALTENIR FRANCISCO M. RODRIGUES	UNIDADE: IPIRANGA PASSOS S.A.		

Caderno de Mapas

Bloco	Talhao	Variedade	Estágio de Corte	Amb. Prod.	Data Plantio	Data Último Corte	Área (ha)	Estimativas Área (ha)	Estimativas Finalid	Estimativas Produt.	Prod. Total	Dist.	Esp.	Tipo Corte	Experimento
3 · REG 3			**574 · SAO SEBAS. III**				**IVALDO MAIA RODRIGUES E OUTROS**								
1	2	CTC2	1C	NC	28/02/24	23/05/25	11,90	11,90	1-MO.	115,0	1.368,50	34	1,5	MEC.	
1	3	CTC9007	1C	NC	06/04/24	23/05/25	11,56	11,56	1-MO.	115,0	1.329,40	34	1,5	MEC.	
1	4	CTC9007	1C	NC	06/04/24	23/05/25	9,25	9,25	1-MO.	115,0	1.063,75	34	1,5	MEC.	
1	5	CTC9007	1C	NC	07/04/24	23/05/25	15,77	15,77	1-MO.	115,0	1.813,55	34	1,5	MEC.	
1	6	CTC9007	1C	NC	07/04/24	23/05/25	16,01	16,01	1-MO.	115,0	1.841,15	34	1,5	MEC.	
1	7	CTC9007	1C	NC	16/04/24	23/05/25	0,16	0,16	1-MO.	115,0	18,40	34	1,5	MEC.	
Total/Média (3 / 574 · SAO SEBAS. III)							64,65	64,65		115,0	7.434,75				

N: 7733449.65785052
E: 332098.31974292
LAT: −20°29'26.0285984" (−20.49056349955)
LONG: −46°36'37.3097355" (−46.61036381542)

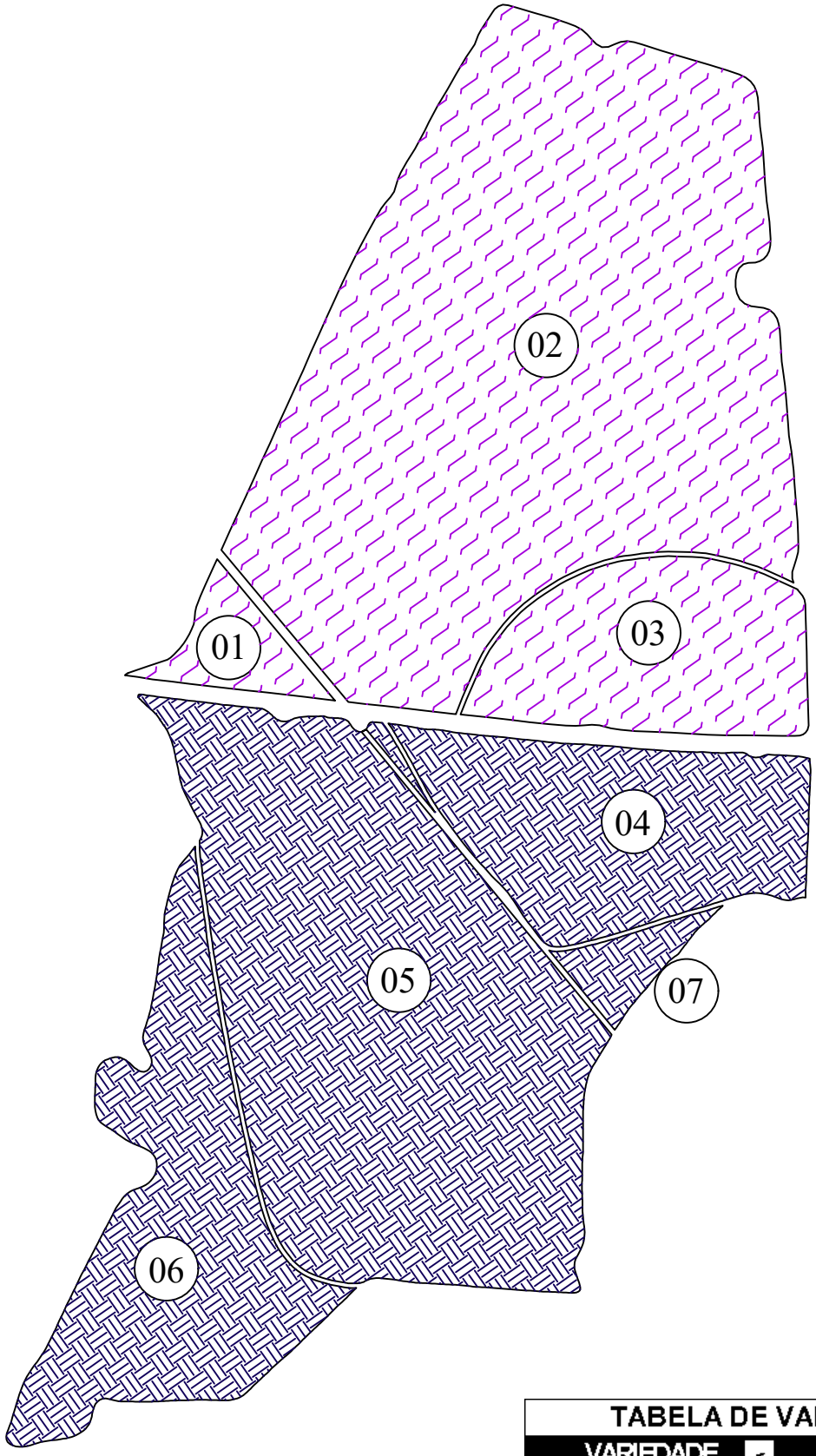

CTC - 9006
CTC - 9007

TABELA DE VARIEDADE	
VARIEDADE	ÁREA
CTC9006	38,39
CTC9007	38,53
Total Geral	**76,92**

IPIRANGA AGROINDUSTRIAL

PROJETO: CADERNO DE MAPA 25´26	DATA: 21-07-2025	ESCALA: 1:5000	TOPÓGRAFO: CRISTIAN
FAZENDA: 575 - ALVORADA/MANGUEIRA	MUNICÍPIO: PASSOS - MG		ÁREA (ha): 76,92
PROPRIETÁRIO: MARCO THULYO MAIA RODRIGUES	UNIDADE: IPIRANGA PASSOS S.A.		

Caderno de Mapas

Bloco	Talhao	Variedade	Estágio de Corte	Amb. Prod.	Data Plantio	Último Corte	Área (ha)	Estimativas Área (ha)	Finalid	Produt.	Prod. Total	Dist.	Esp.	Tipo Corte	Experimento
3 · REG 3			**575 · ALVORADA/MANG.**					**MARCO THULYO MAIA RODRIGUES**							
1	1	CTC9007	1C	NC	07/04/24	16/05/25	1,37	1,37	1-MO.	118,0	161,66	35,5	1,5	MEC.	
1	2	CTC9007	1C	NC	07/04/24	16/05/25	31,17	31,17	1-MO.	118,0	3.678,06	35,5	1,5	MEC.	
1	3	CTC9007	1C	NC	07/04/24	16/05/25	5,99	5,99	1-MO.	118,0	706,82	35,5	1,5	MEC.	
1	4	CTC9006	FORM	NC	07/03/25		7,37	0,00	.		0,00	35,5	1,5	N/D	
1	5	CTC9006	FORM	NC	06/03/25		21,01	0,00	.		0,00	35,5	1,5	N/D	
1	6	CTC9006	FORM	NC	06/03/25		9,12	0,00	.		0,00	35,5	1,5	N/D	
1	7	CTC9006	FORM	NC	06/03/25		0,89	0,00	.		0,00	35,5	1,5	N/D	
Total/Média (3 / 575 · ALVORADA/MANG.)							76,92	38,53		118,0	4.546,54				

N: 7726461.36334216
E: 334393.31352924
LAT: −20°33'14.0004116" (−20.55388900322)
LONG: −46°35'20.4552299" (−46.58901534164)

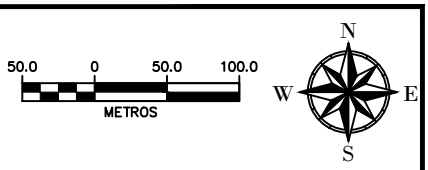

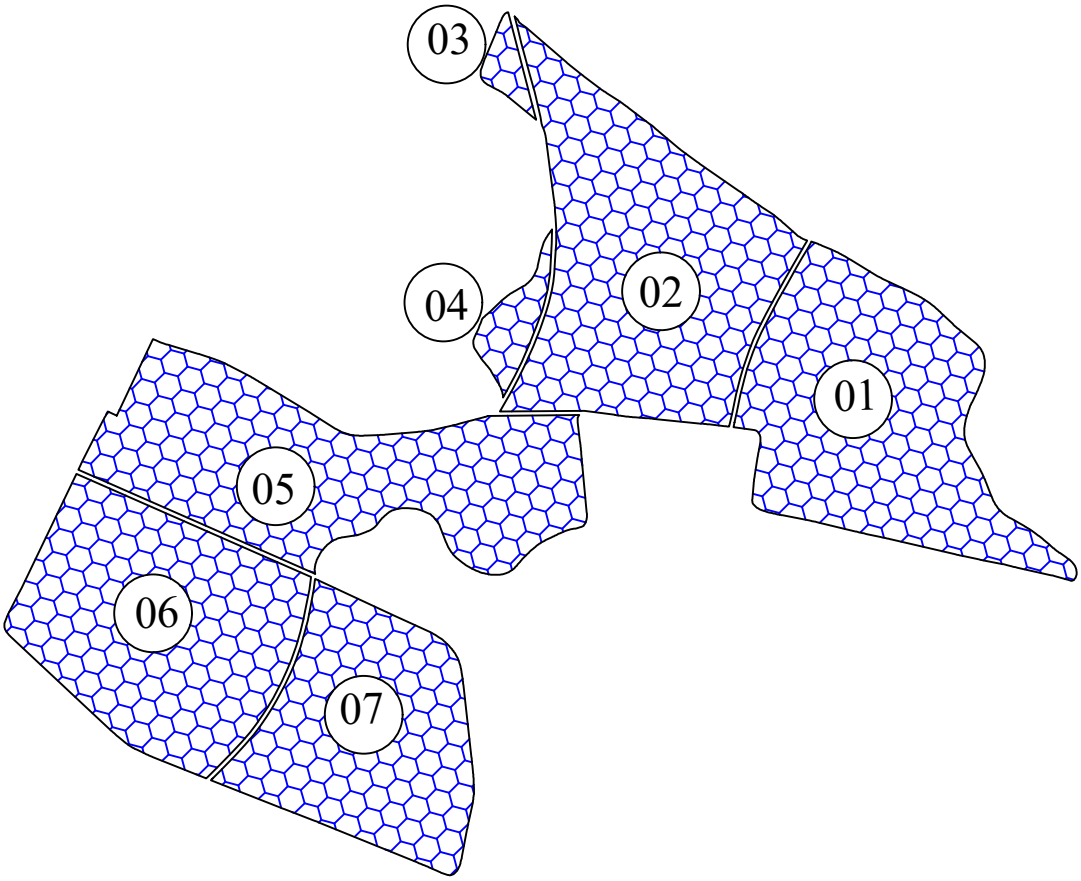

IAC SP 04-6007

TABELA DE VARIEDADE	
VARIEDADE	ÁREA
IACSP04-6007	40,06
Total Geral	**40,06**

IPIRANGA AGROINDUSTRIAL

PROJETO: CADERNO DE MAPA 25´26	DATA: 21-07-2025	ESCALA: 1:5000	TOPÓGRAFO: CRISTIAN
FAZENDA: 576 - ÁGUA SERENA	MUNICÍPIO: DELFINÓPOLIS - MG		ÁREA (ha): 40,06
PROPRIETÁRIO: IVO PIMENTA MATTAR SOARES	UNIDADE: IPIRANGA PASSOS		

Caderno de Mapas

Bloco	Talhao	Variedade	Estágio de Corte	Amb. Prod.	Data Plantio	Último Corte	Área (ha)	Estimativas Área (ha)	Finalid	Produt.	Prod. Total	Dist.	Esp.	Tipo Corte	Experimento
3 · REG 3			**576 · AGUA SERENA**				**IVO PIMENTA MATTAR SOARES**								
1	1	IACSP04-6007	1C	NC	16/04/24	25/07/25	8,00	8,00	1-MO.	120,0	960,00	27	1,5	MEC.	
1	2	IACSP04-6007	1C	NC	17/04/24	25/07/25	8,82	8,82	1-MO.	120,0	1.058,40	27	1,5	MEC.	
1	3	IACSP04-6007	1C	NC	18/04/24	25/07/25	0,34	0,34	1-MO.	120,0	40,80	27	1,5	MEC.	
1	4	IACSP04-6007	1C	NC	18/04/24	25/07/25	0,66	0,66	1-MO.	120,0	79,20	27	1,5	MEC.	
1	5	IACSP04-6007	1C	NC	13/04/24	25/07/25	8,60	8,60	1-MO.	120,0	1.032,00	27	1,5	MEC.	
1	6	IACSP04-6007	1C	NC	12/04/24	25/07/25	7,57	7,57	1-MO.	120,0	908,40	27	1,5	MEC.	
1	7	IACSP04-6007	1C	NC	17/04/24	25/07/25	6,07	6,07	1-MO.	120,0	728,40	27	1,5	MEC.	
Total/Média (3 / 576 · AGUA SERENA)							40,06	40,06		120,0	4.807,20				

N: 7729777.140
E: 330528.5597
LAT: -20°31'24.9434" (-20.52359538)
LONG: -46°37'32.7414" (-46.62576151)

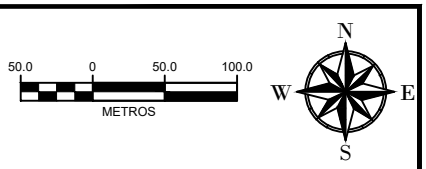

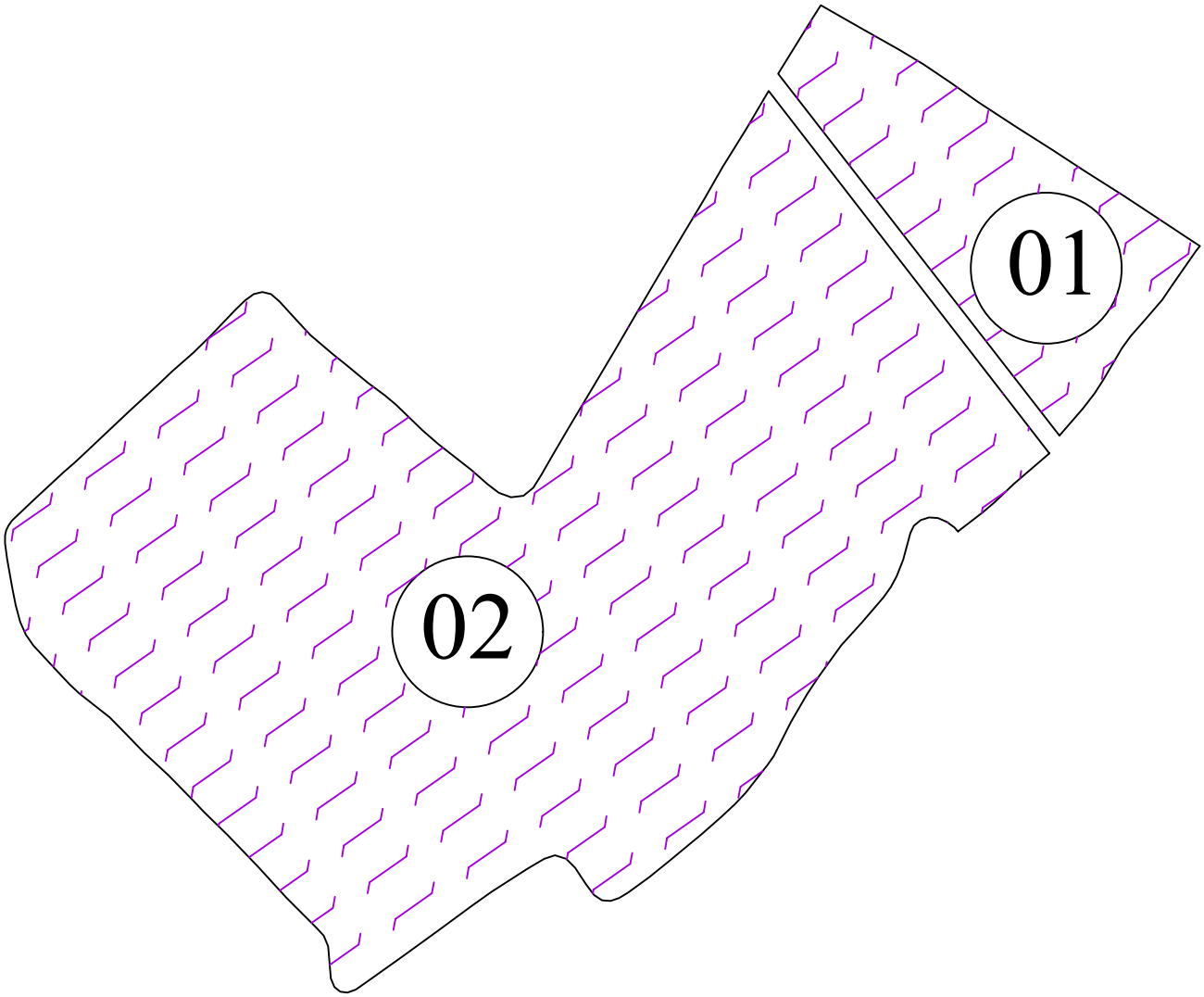

CTC - 9007

TABELA DE VARIEDADE	
VARIEDADE	ÁREA
CTC9007	11,10
Total Geral	**11,10**

IPIRANGA AGROINDUSTRIAL

PROJETO: CADERNO DE MAPA 25´26	DATA: 21-07-2025	ESCALA: 1:5000	TOPÓGRAFO: CRISTIAN
FAZENDA: 577 - TRÊS IRMÃOS	MUNICÍPIO: PASSOS - MG		ÁREA (ha): 11,10
PROPRIETÁRIO: ROMELIO FRANCISCO DA SILVA	UNIDADE: IPIRANGA PASSOS S.A.		

Caderno de Mapas

Bloco	Talhao	Variedade	Estágio de Corte	Amb. Prod.	Data Plantio	Data Último Corte	Área (ha)	Estimativas Área (ha)	Estimativas Finalid	Estimativas Produt.	Prod. Total	Dist.	Esp.	Tipo Corte	Experimento
3 · REG 3			**577 · TRES IRMAOS**				**ROMELIO FRANCISCO DA SILVA**								
1	1	CTC9007	1C	NC	11/04/24	28/05/25	1,53	1,53	1-MO.	110,0	168,30	34	1,5	MEC.	
1	2	CTC9007	1C	NC	11/04/24	28/05/25	9,57	9,57	1-MO.	110,0	1.052,70	34	1,5	MEC.	
Total/Média (3 / 577 · TRES IRMAOS)							11,10	11,10		110,0	1.221,00				

N: 7731870.22275259
E: 331756.09890608
LAT: −20°30'17.2778948" (−20.50479941521)
LONG: −46°36'49.6573481" (−46.61379370782)

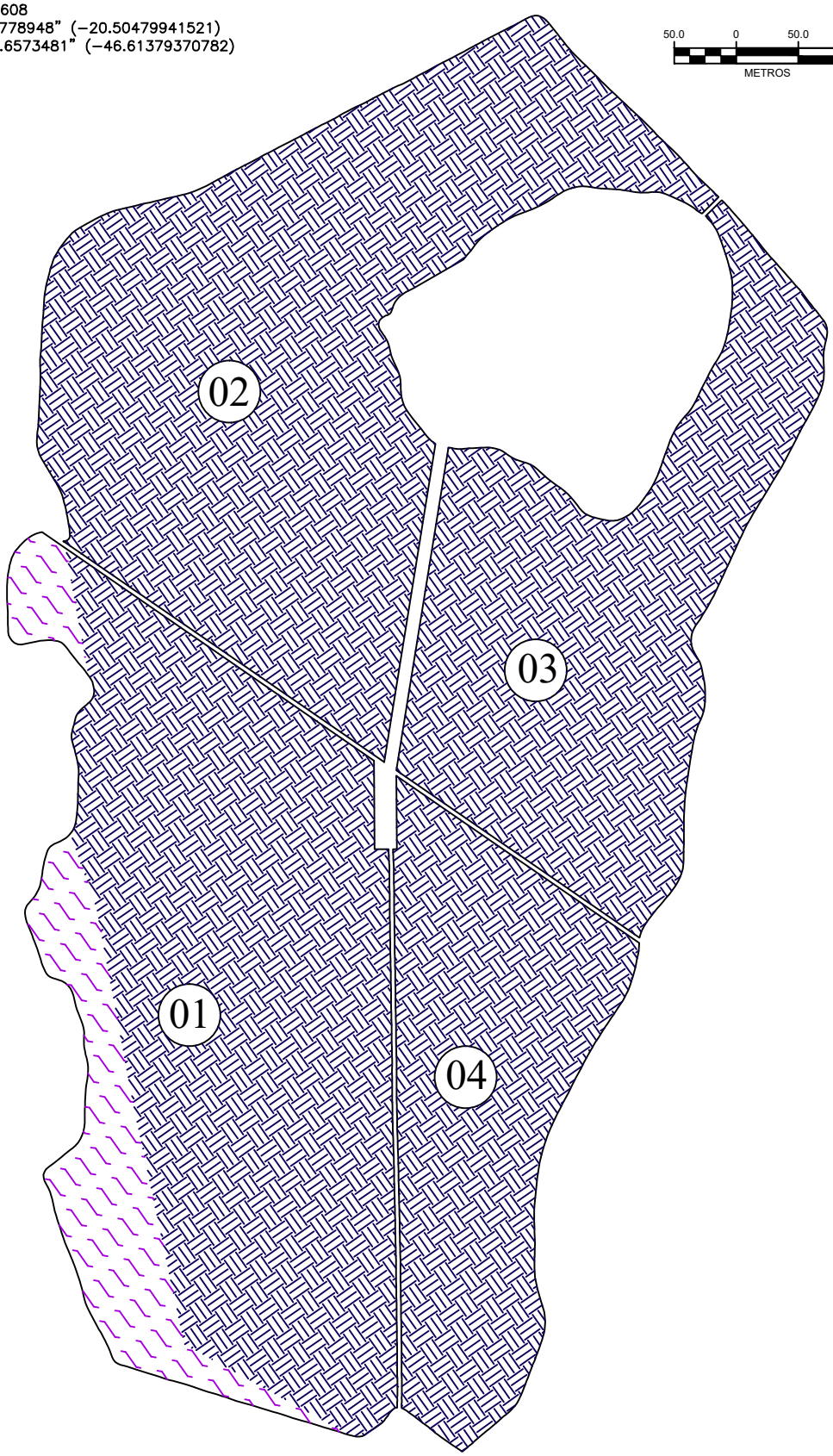

CTC - 9007
CTC - 9006

TABELA DE VARIEDADE	
VARIEDADE	ÁREA
CTC9006	82,41
CTC9007	5,84
Total Geral	**88,25**

IPIRANGA AGROINDUSTRIAL

PROJETO: CADERNO DE MAPA 25´26	DATA: 21-07-2025	ESCALA: 1:5000	TOPÓGRAFO: CRISTIAN
FAZENDA: 578 - BOA VISTA II	MUNICÍPIO: DELFINOPOLIS		ÁREA (ha): 88,25
PROPRIETÁRIO: IVALDO MAIA RODRIGUES	UNIDADE: IPIRANGA PASSOS S.A.		

Caderno de Mapas

Bloco	Talhao	Variedade	Estágio de Corte	Amb. Prod.	Data Plantio	Último Corte	Área (ha)	Estimativas Área (ha)	Finalid	Produt.	Prod. Total	Dist.	Esp.	Tipo Corte	Experimento
3 · REG 3			**578 · BOA VISTA II**					**IVALDO MAIA RODRIGUES E OUTROS**							
1	1	CTC9006	FORM	NC	06/03/25		24,96	0,00	.		0,00	34	1,5	N/D	
1	1	CTC9007	FORM	NC	06/03/25		5,84	0,00	.		0,00	34	1,5	N/D	
1	2	CTC9006	FORM	NC	05/03/25		27,55	0,00	.		0,00	34	1,5	N/D	
1	3	CTC9006	FORM	NC	27/02/25		17,35	0,00	.		0,00	34	1,5	N/D	
1	4	CTC9006	FORM	NC	01/03/25		12,55	0,00	.		0,00	34	1,5	N/D	
1	201	A DEFINIR	EXP	NC	01/01/25		44,60	0,00	.		0,00	34	1,5	N/D	
1	202	A DEFINIR	EXP	NC	01/01/25		3,12	0,00	.		0,00	34	1,5	N/D	
Total/Média (3 / 578 · BOA VISTA II)							135,97	0,00			0,00				

N: 7707707.65651955
E: 326194.28773083
LAT: −20°43'21.1323333" (−20.72253675924)
LONG: −46°40'10.1644705" (−46.66949013069)

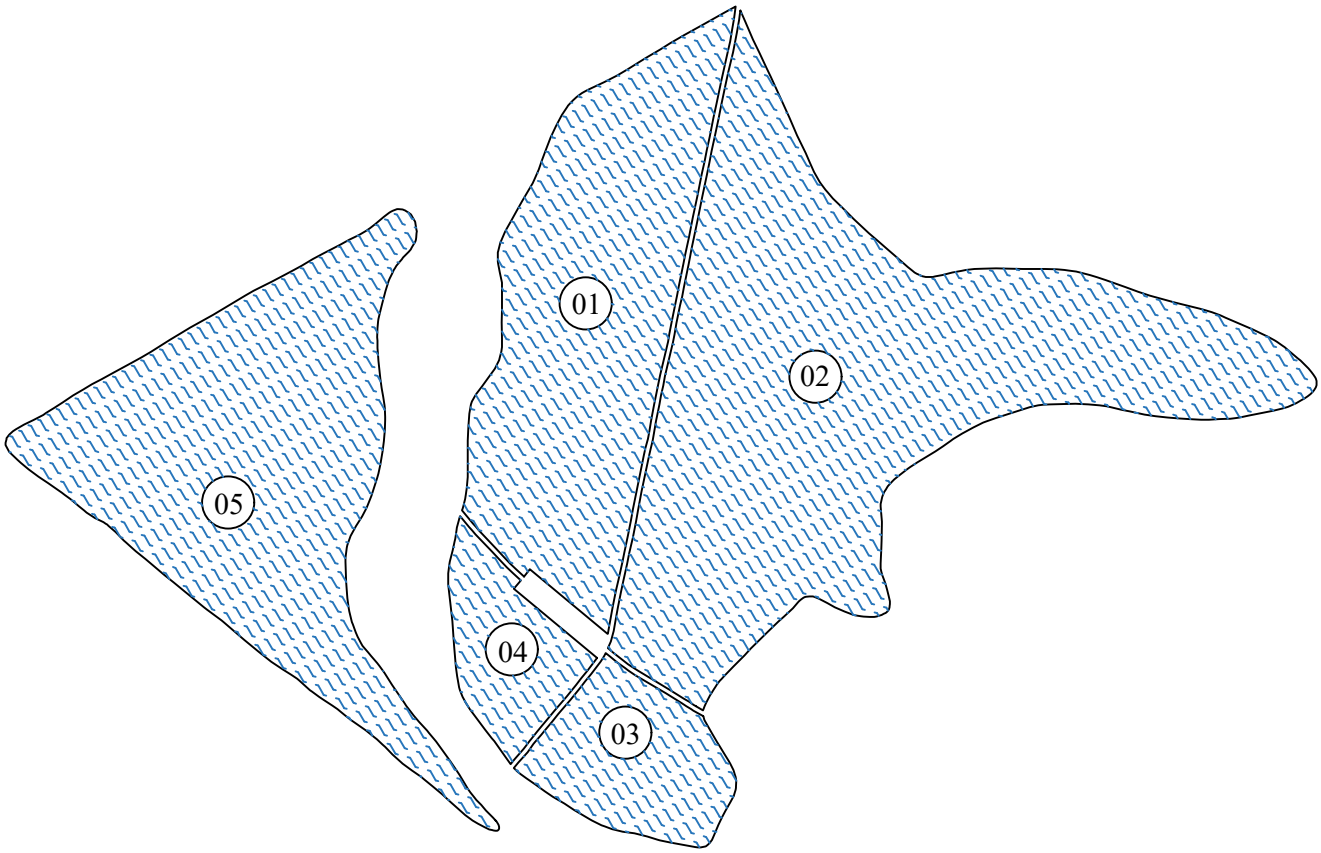

TABELA DE VARIEDADE	
VARIEDADE	ÁREA
CTC9008	39,37
Total Geral	**39,37**

CTC - 9008

IPIRANGA AGROINDUSTRIAL

PROJETO: CADERNO DE MAPA 25´26	DATA: 21-07-2025	ESCALA: 1:5000	TOPÓGRAFO: CRISTIAN
FAZENDA: 579 - LAVRINHA	MUNICÍPIO: PASSOS MG		ÁREA (ha): 39,37
PROPRIETÁRIO: KARINA MARCELA CAPATO	UNIDADE: IPIRANGA PASSOS		

Caderno de Mapas

Bloco	Talhao	Variedade	Estágio de Corte	Amb. Prod.	Data Plantio	Último Corte	Área (ha)	Estimativas Área (ha)	Finalid	Produt.	Prod. Total	Dist.	Esp.	Tipo Corte	Experimento
3 · REG 3			**579 · LAVRINHA**				**MARIA EDUARDA DE SOUZA CAPATO**								
1	1	CTC9008	FORM	NC	04/09/24		8,64	0,00	.		0,00	28	1,5	N/D	
1	2	CTC9008	FORM	NC	03/09/24		16,36	0,00	.		0,00	28	1,5	N/D	
1	3	CTC9008	FORM	NC	03/09/24		2,47	0,00	.		0,00	28	1,5	N/D	
1	4	CTC9008	FORM	NC	03/09/24		1,79	0,00	.		0,00	28	1,5	N/D	
1	5	CTC9008	FORM	NC	04/09/24		10,11	0,00	.		0,00	28	1,5	N/D	
Total/Média (3 / 579 · LAVRINHA)							39,37	0,00			0,00				

N: 7713853.634
E: 335030.8915
LAT: −20°40'4.1716" (−20.66782545)
LONG: −46°35'2.6806" (−46.58407794)

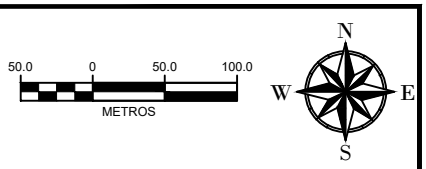

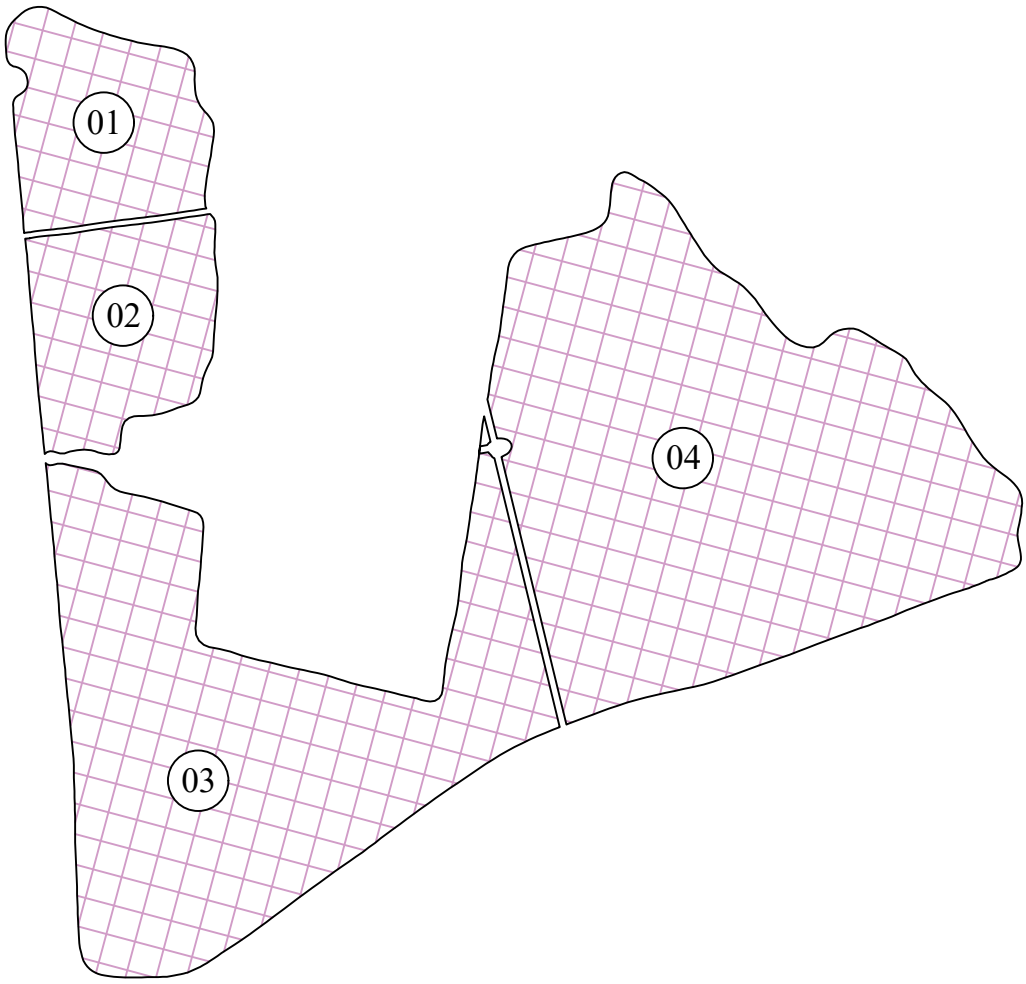

IAC CTC 07-7207

TABELA DE VARIEDADE	
VARIEDADE	ÁREA
IACCTC07-7207	27,32
Total Geral	**27,32**

IPIRANGA AGROINDUSTRIAL	PROJETO: CADERNO DE MAPA 25´26	DATA: 21-07-2025 / ESCALA: 1:5000	TOPÓGRAFO: CRISTIAN
	FAZENDA: 580 - MANGUEIRA II	MUNICÍPIO: DELFINOPOLIS	ÁREA (ha): 27,32
	PROPRIETÁRIO: RAUL	UNIDADE: IPIRANGA PASSOS S.A.	

Caderno de Mapas

Bloco	Talhao	Variedade	Estágio de Corte	Amb. Prod.	Data Plantio	Último Corte	Área (ha)	Estimativas Área (ha)	Finalid	Produt.	Prod. Total	Dist.	Esp.	Tipo Corte	Experimento
3 · REG 3			**580 · MANGUEIRA II**					**RAUL MEDEIROS CINTRA E OUTROS**							
1	1	IACCTC07-7207	FORM	NC	26/02/25		2,52	0,00	.		0,00	36	1,5	N/D	
1	2	IACCTC07-7207	FORM	NC	26/02/25		2,59	0,00	.		0,00	36	1,5	N/D	
1	3	IACCTC07-7207	FORM	NC	27/02/25		9,73	0,00	.		0,00	36	1,5	N/D	
1	4	IACCTC07-7207	FORM	NC	27/02/25		12,48	0,00	.		0,00	36	1,5	N/D	
Total/Média (3 / 580 · MANGUEIRA II)							27,32	0,00			0,00				

N: 7713853.634
E: 335030.8915
LAT: −20°40'4.1716" (−20.66782545)
LONG: −46°35'2.6806" (−46.58407794)

50.0 0 50.0 100.0
METROS

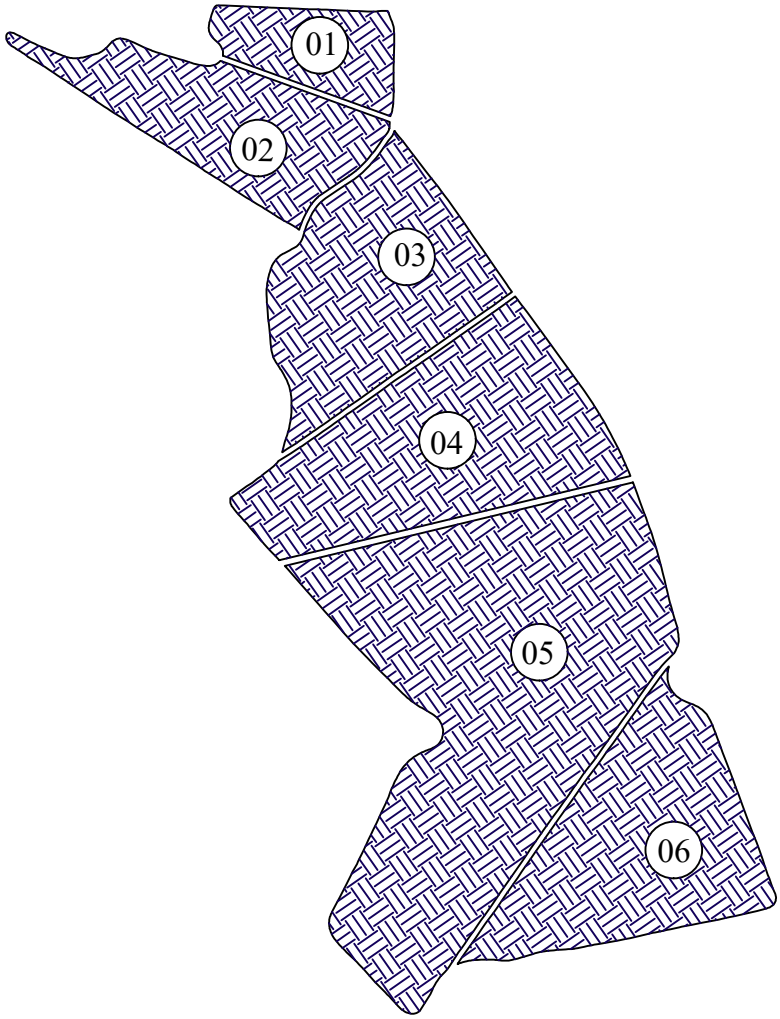

CTC - 9006

TABELA DE VARIEDADE	
VARIEDADE	ÁREA
CTC9006	22,40
Total Geral	**22,40**

IPIRANGA AGROINDUSTRIAL

PROJETO: CADERNO DE MAPA 25´26	DATA: 22-07-2025	ESCALA: 1:5000	TOPÓGRAFO: CRISTIAN
FAZENDA: 582 - MANGUEIRA III	MUNICÍPIO: PASSOS - MG		ÁREA (ha): 22,40
PROPRIETÁRIO: IVALTENIR	UNIDADE: IPIRANGA PASSOS S.A.		

Caderno de Mapas

Bloco	Talhao	Variedade	Estágio de Corte	Amb. Prod.	Data Plantio	Data Último Corte	Área (ha)	Estimativas Área (ha)	Estimativas Finalid	Estimativas Produt.	Prod. Total	Dist.	Esp.	Tipo Corte	Experimento
3 · REG 3			**582 · MANGUEIRA III**				**IVALTENIR FRANCISCO MAIA RODRIGUES**								
1	1	CTC9006	FORM	NC	11/02/25		1,07	0,00	.		0,00	36	1,5	N/D	
1	2	CTC9006	FORM	NC	11/02/25		2,34	0,00	.		0,00	36	1,5	N/D	
1	3	CTC9006	FORM	NC	12/02/25		3,16	0,00	.		0,00	36	1,5	N/D	
1	4	CTC9006	FORM	NC	12/02/25		4,05	0,00	.		0,00	36	1,5	N/D	
1	5	CTC9006	FORM	NC	12/02/25		8,26	0,00	.		0,00	36	1,5	N/D	
1	6	CTC9006	FORM	NC	12/02/25		3,52	0,00	.		0,00	36	1,5	N/D	
Total/Média (3 / 582 · MANGUEIRA III)							22,40	0,00			0,00				

N: 7729049.93406835
E: 329250.64605423
LAT: −20°31'48.1746988" (−20.53004852744)
LONG: −46°38'17.1024092" (−46.63808400256)

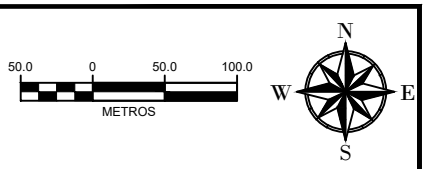

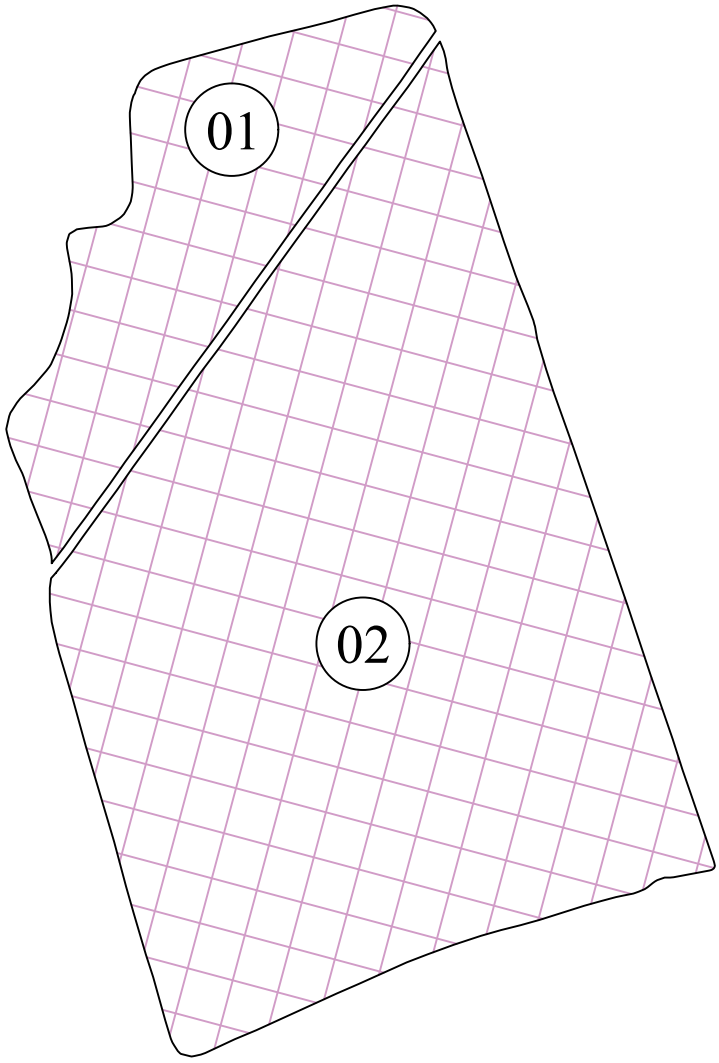

IAC CTC 07-7207

TABELA DE VARIEDADE	
VARIEDADE	ÁREA
IACCTC07-7207	13,19
Total Geral	**13,19**

IPIRANGA AGROINDUSTRIAL	PROJETO: CADERNO DE MAPA 25´26	DATA: 22-07-2025 / ESCALA: 1:5000	TOPÓGRAFO: CRISTIAN
	FAZENDA: 583 - SERRINHA II	MUNICÍPIO: DELFINOPOLIS MG	ÁREA (ha): 13,19
	PROPRIETÁRIO: IVALTENIR FRANCISCO M RODRIGUES	UNIDADE: IPIRANGA PASSOS S.A.	

Caderno de Mapas

Bloco	Talhao	Variedade	Estágio de Corte	Amb. Prod.	Data Plantio	Último Corte	Área (ha)	Estimativas Área (ha)	Finalid	Produt.	Prod. Total	Dist.	Esp.	Tipo Corte	Experimento
3 · REG 3			**583 · SERRINHA II**					**IVALTENIR FRANCISCO MAIA RODRIGUES**							
1	1	IACCTC07-7207	1C	NC	12/12/24		2,51	0,00	.		0,00	33	1,5	N/D	
1	2	IACCTC07-7207	1C	NC	11/12/24		10,68	0,00	.		0,00	33	1,5	N/D	
Total/Média (3 / 583 · SERRINHA II)							13,19	0,00			0,00				

N: 7741835.44889601
E: 316046.82478669
LAT: −20°24'46.5489047" (−20.41293025129)
LONG: −46°45'46.7208084" (−46.76297800234)

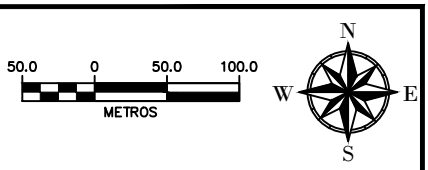

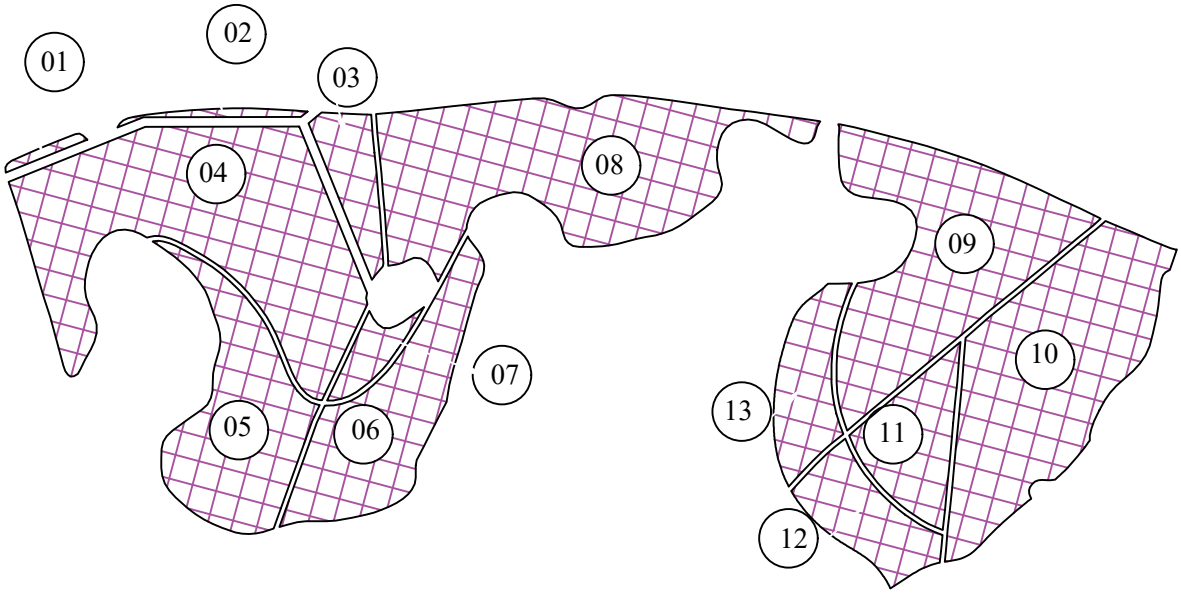

TABELA DE VARIEDADE	
VARIEDADE	ÁREA
IACCTC07-8008	27,13
Total Geral	**27,13**

IAC CTC 07-8008

IPIRANGA AGROINDUSTRIAL	PROJETO: CADERNO DE MAPA 25´26	DATA: 22-07-2025	ESCALA: 1:5000	TOPÓGRAFO: LUÍS DUARTE
	FAZENDA: 584 - NOVA BARRA II	MUNICÍPIO: PASSOS - MG		ÁREA (ha): 27,13
	PROPRIETÁRIO:	UNIDADE: IPIRANGA PASSOS - MG		CÓDIGO: 584

Caderno de Mapas

Bloco	Talhao	Variedade	Estágio de Corte	Amb. Prod.	Data Plantio	Último Corte	Área (ha)	Estimativas Área (ha)	Finalid	Produt.	Prod. Total	Dist.	Esp.	Tipo Corte	Experimento
3 · REG 3			**584 · NOVA BARRA II**				**PAULO DE ARAUJO RODRIGUES E OUTROS**								
1	1	IACCTC07-8008	FORM A	NC	15/04/24		0,08	0,00	.		0,00	52	1,5	N/D	
1	2	IACCTC07-8008	1C	NC	16/04/24	17/09/25	0,12	0,12	1-MO.	125,0	15,00	52	1,5	MEC.	
1	3	IACCTC07-8008	1C	NC	16/04/24	17/09/25	0,68	0,68	1-MO.	125,0	85,00	52	1,5	MEC.	
1	4	IACCTC07-8008	1C	NC	16/04/24	17/09/25	5,38	5,38	1-MO.	125,0	672,50	52	1,5	MEC.	
1	5	IACCTC07-8008	1C	NC	16/04/24	17/09/25	2,42	2,42	1-MO.	125,0	302,50	52	1,5	MEC.	
1	6	IACCTC07-8008	1C	NC	16/04/24	17/09/25	2,24	2,24	1-MO.	125,0	280,00	52	1,5	MEC.	
1	7	IACCTC07-8008	1C	NC	16/04/24	17/09/25	0,33	0,33	1-MO.	125,0	41,25	52	1,5	MEC.	
1	8	IACCTC07-8008	1C	NC	15/04/24	17/09/25	4,71	4,71	1-MO.	125,0	588,75	52	1,5	MEC.	
1	9	IACCTC07-8008	1C	NC	15/04/24		3,85	3,85	1-MO.	125,0	481,25	52	1,5	MEC.	
1	10	IACCTC07-8008	1C	NC	15/04/24		4,15	4,15	1-MO.	125,0	518,75	52	1,5	MEC.	
1	11	IACCTC07-8008	1C	NC	16/04/24		1,15	1,15	1-MO.	125,0	143,75	52	1,5	MEC.	
1	12	IACCTC07-8008	1C	NC	16/04/24		1,02	1,02	1-MO.	125,0	127,50	52	1,5	MEC.	
1	13	IACCTC07-8008	FORM A	NC	16/04/24		1,00	1,00	1-MO.	125,0	125,00	52	1,5	MEC.	
Total/Média (3 / 584 · NOVA BARRA II)							27,13	27,05		125,0	3.381,25				

N: 7741412.37337805
E: 317657.57111203
LAT: -20°25'0.8651410" (-20.41690698361)
LONG: -46°44'51.3219171" (-46.74758942142)

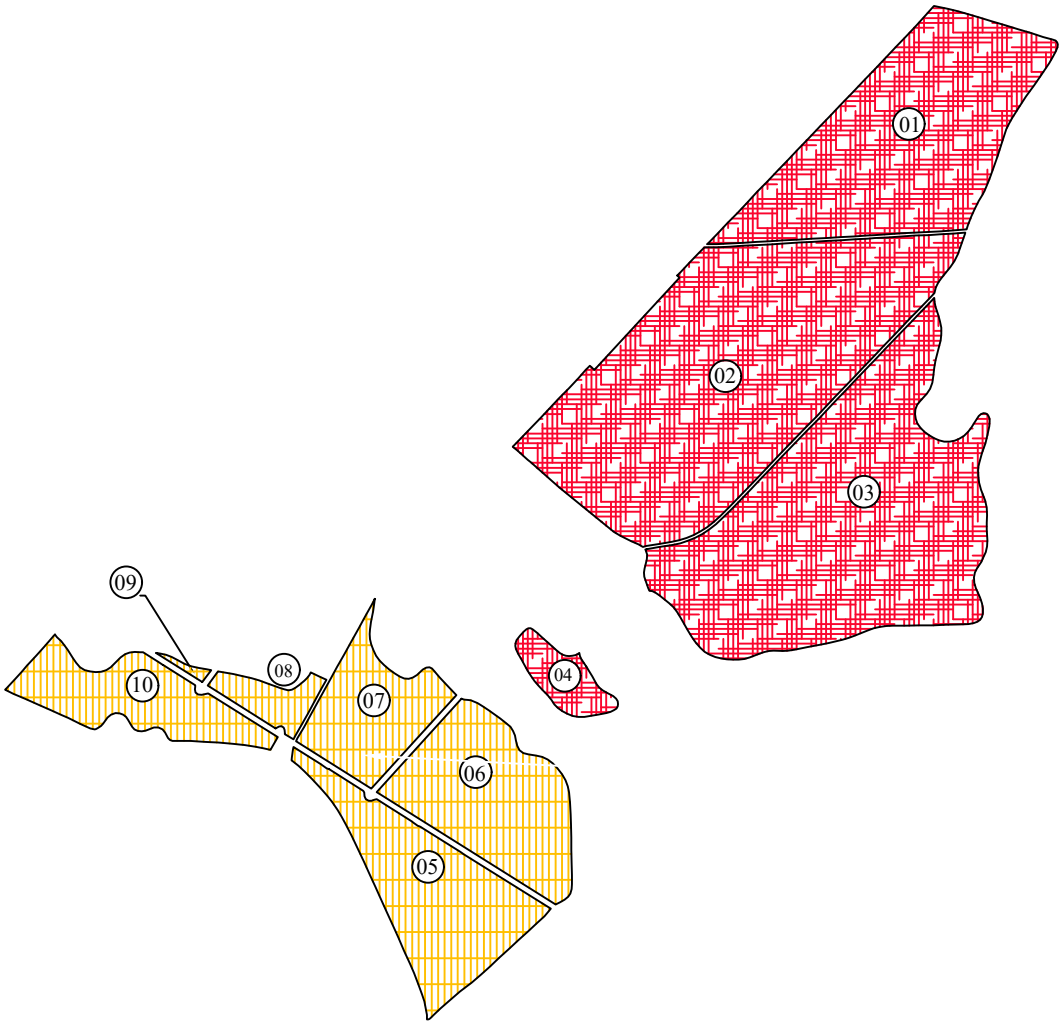

RB 98-5476
IAC SP 01-5503

TABELA DE VARIEDADE	
VARIEDADE	ÁREA
IACSP01-5503	46,42
RB985476	18,75
Total Geral	65,17

IPIRANGA AGROINDUSTRIAL

PROJETO: CADERNO DE MAPA 25´26	DATA: 13/06/2025	ESCALA: 1:5000	TOPÓGRAFO: CRISTIAN
FAZENDA: 585 - SANTA CRUZ II	MUNICÍPIO: DELFINOPOLIS - MG		ÁREA (ha): 65,17
PROPRIETÁRIO: PAULO RODRIGUES	UNIDADE: IPIRANGA PASSOS S.A.		

Caderno de Mapas

Bloco	Talhao	Variedade	Estágio de Corte	Amb. Prod.	Data Plantio	Último Corte	Área (ha)	Estimativas Área (ha)	Finalid	Produt.	Prod. Total	Dist.	Esp.	Tipo Corte	Experimento
3 · REG 3			**585 · SANTA CRUZ II**				**PAULO DE ARAUJO RODRIGUES E OUTROS**								
1	1	IACSP01-5503	1C	NC	09/04/24	02/07/25	10,66	10,66	1-MO.	130,0	1.385,80	26	1,5	MEC.	
1	2	IACSP01-5503	1C	NC	10/04/24	02/07/25	18,24	18,24	1-MO.	130,0	2.371,20	26	1,5	MEC.	
1	3	IACSP01-5503	1C	NC	09/04/24	02/07/25	16,42	16,42	1-MO.	130,0	2.134,60	26	1,5	MEC.	
1	4	IACSP01-5503	1C	NC	10/04/24	02/07/25	1,10	1,10	1-MO.	130,0	143,00	26	1,5	MEC.	
1	5	RB985476	1A	NC	30/04/24	07/07/25	5,55	5,55	1-MO.	130,0	721,50	26	1,5	MEC.	
1	6	RB985476	1A	NC	30/04/24	07/07/25	5,50	5,50	1-MO.	130,0	715,00	26	1,5	MEC.	
1	7	RB985476	1A	NC	30/04/24	07/07/25	3,23	3,23	1-MO.	125,0	403,75	26	1,5	MEC.	
1	8	RB985476	1A	NC	29/04/24	07/07/25	0,95	0,95	1-MO.	125,0	118,75	26	1,5	MEC.	
1	9	RB985476	1A	NC	29/04/24	07/07/25	0,09	0,09	1-MO.	130,0	11,70	26	1,5	MEC.	
1	10	RB985476	1A	NC	30/04/24	07/07/25	3,43	3,43	1-MO.	130,0	445,90	26	1,5	MEC.	
Total/Média (3 / 585 · SANTA CRUZ II)							65,17	65,17		129,7	8.451,20				

N: 7713853.634
E: 335030.8915
LAT: −20°40'4.1716" (−20.66782545)
LONG: −46°35'2.6806" (−46.58407794)

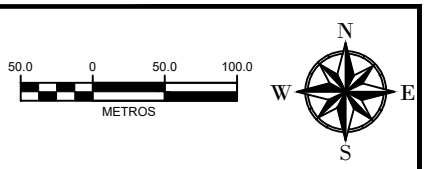

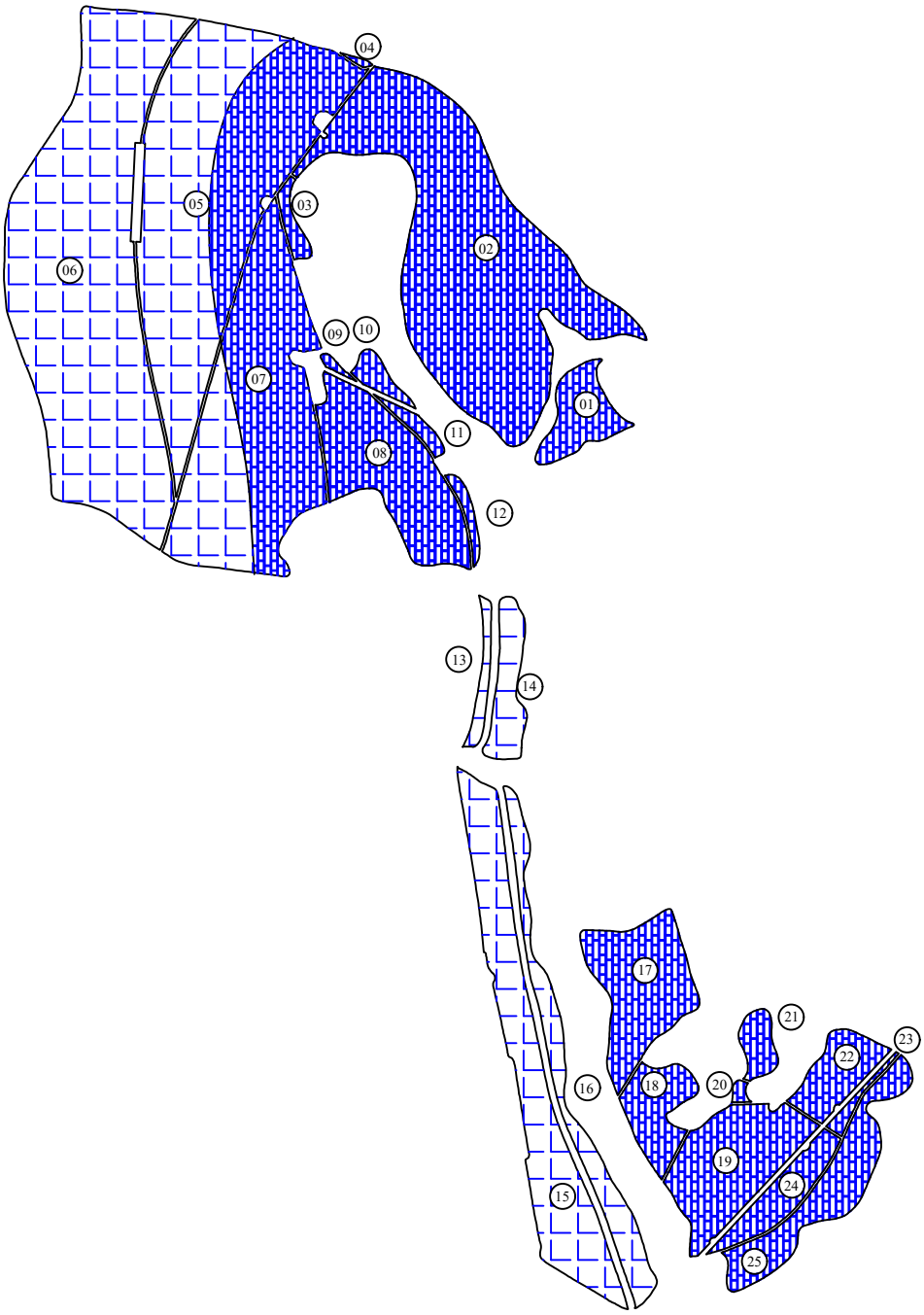

CTC - 2
RB 00-5014

TABELA DE VARIEDADE	
VARIEDADE	ÁREA
RB 00-5014	65,94
CTC-2	54,55
Total Geral	**120,49**

IPIRANGA AGROINDUSTRIAL

PROJETO: CADERNO DE MAPA 25'26	DATA: 13/06/2025	ESCALA: 1:5000	TOPÓGRAFO: CRISTIAN
FAZENDA: 586 - BARRA DA EXTREMA	MUNICÍPIO: DELFINOPOLIS - MG		ÁREA (ha): 120,49
PROPRIETÁRIO: PAULO RODRIGUES	UNIDADE: IPIRANGA PASSOS S.A.		

Caderno de Mapas

Bloco	Talhao	Variedade	Estágio de Corte	Amb. Prod.	Data Plantio	Último Corte	Área (ha)	Estimativas Área (ha)	Finalid	Produt.	Prod. Total	Dist.	Esp.	Tipo Corte	Experimento
3 · REG 3			**586 · BARRA DA EXTREM**				**PAULO DE ARAUJO RODRIGUES E OUTROS**								
1	1	RB005014	FORM	IN	17/04/25		1,97	0,00	.		0,00	49,8	1,5	N/D	
1	2	RB005014	FORM	IN	13/04/25		19,29	0,00	.		0,00	49,8	1,5	N/D	
1	3	RB005014	FORM	IN	09/04/25		0,46	0,00	.		0,00	49,8	1,5	N/D	
1	4	RB005014	FORM	IN	09/04/25		0,06	0,00	.		0,00	49,8	1,5	N/D	
1	5	CTC2	FORM	IN	03/04/25		12,08	0,00	.		0,00	49,8	1,5	N/D	
1	5	RB005014	FORM	IN	03/04/25		7,44	0,00	.		0,00	49,8	1,5	N/D	
1	6	CTC2	FORM	IN	10/04/25		23,50	0,00	.		0,00	49,8	1,5	N/D	
1	7	CTC2	FORM	IN	10/04/25		4,63	0,00	.		0,00	49,8	1,5	N/D	
1	7	RB005014	FORM	IN	10/04/25		9,19	0,00	.		0,00	49,8	1,5	N/D	
1	8	RB005014	FORM	IN	11/04/25		6,00	0,00	.		0,00	49,8	1,5	N/D	
1	9	RB005014	FORM	IN	10/04/25		0,10	0,00	.		0,00	49,8	1,5	N/D	
1	10	RB005014	FORM	IN	10/04/25		0,55	0,00	.		0,00	49,8	1,5	N/D	
1	11	RB005014	FORM	IN	11/04/25		0,39	0,00	.		0,00	49,8	1,5	N/D	
1	12	RB005014	FORM	IN	08/04/25		0,34	0,00	.		0,00	49,8	1,5	N/D	
1	13	CTC2	FORM	IN	08/04/25		0,59	0,00	.		0,00	49,8	1,5	N/D	
1	14	CTC2	FORM	IN	31/03/25		1,75	0,00	.		0,00	49,8	1,5	N/D	
1	15	CTC2	FORM	IN	01/04/25		8,49	0,00	.		0,00	49,8	1,5	N/D	
1	16	CTC2	FORM	IN	14/04/25		3,51	0,00	.		0,00	49,8	1,5	N/D	
1	17	RB005014	FORM	IN	14/04/25		4,68	0,00	.		0,00	49,8	1,5	N/D	
1	18	RB005014	FORM	IN	14/04/25		2,08	0,00	.		0,00	49,8	1,5	N/D	
1	19	RB005014	FORM	IN	14/04/25		4,88	0,00	.		0,00	49,8	1,5	N/D	
1	20	RB005014	FORM	IN	15/04/25		0,12	0,00	.		0,00	49,8	1,5	N/D	
1	21	RB005014	FORM	IN	14/04/25		0,79	0,00	.		0,00	49,8	1,5	N/D	
1	22	RB005014	FORM	IN	14/04/25		1,87	0,00	.		0,00	49,8	1,5	N/D	
1	23	RB005014	FORM	IN	15/04/25		0,28	0,00	.		0,00	49,8	1,5	N/D	
1	24	RB005014	FORM	IN	15/04/25		1,76	0,00	.		0,00	49,8	1,5	N/D	
1	25	RB005014	FORM	IN	15/04/25		3,69	0,00	.		0,00	49,8	1,5	N/D	
Total/Média (3 / 586 · BARRA DA EXTREM)							120,49	0,00			0,00				

N: 7713853.634
E: 335030.8915
LAT: −20°40'4.1716" (−20.66782545)
LONG: −46°35'2.6806" (−46.58407794)

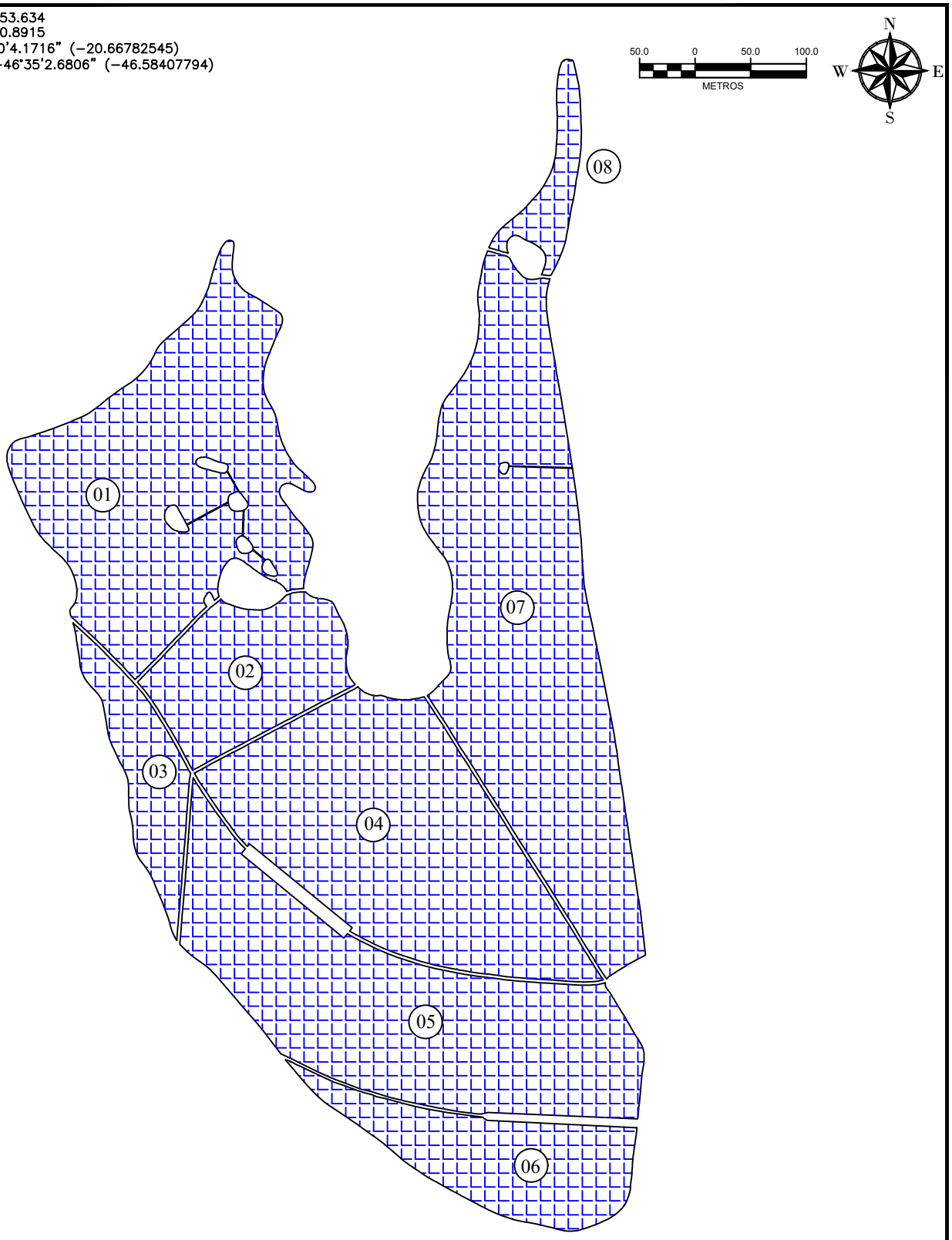

TABELA DE VARIEDADE	
VARIEDADE	ÁREA
CTC 2	78,08
Total Geral	78,08

CTC - 2

IPIRANGA AGROINDUSTRIAL

PROJETO: CADERNO DE MAPA 25'26	DATA: 13/06/2025	ESCALA: 1:5000	TOPÓGRAFO: CRISTIAN
FAZENDA: 587 - MATA VIRGEM	MUNICÍPIO: DELFINOPOLIS - MG		ÁREA (ha): 78,08
PROPRIETÁRIO: PAULO RODRIGUES	UNIDADE: IPIRANGA PASSOS S.A.		

Caderno de Mapas

Bloco	Talhao	Variedade	Estágio de Corte	Amb. Prod.	Data Plantio	Último Corte	Área (ha)	Estimativas Área (ha)	Finalid	Produt.	Prod. Total	Dist.	Esp.	Tipo Corte	Experimento
3 · REG 3			**587 · MATA VIRGEM**				**PAULO DE ARAUJO RODRIGUES E OUTROS**								
1	1	CTC2	FORM	IN	29/03/25		14,78	0,00	.		0,00	51,4	1,5	N/D	
1	2	CTC2	FORM	IN	26/03/25		5,23	0,00	.		0,00	51,4	1,5	N/D	
1	3	CTC2	FORM	IN	26/03/25		2,95	0,00	.		0,00	51,4	1,5	N/D	
1	4	CTC2	FORM	IN	25/03/25		14,37	0,00	.		0,00	51,4	1,5	N/D	
1	5	CTC2	FORM	IN	24/03/25		14,74	0,00	.		0,00	51,4	1,5	N/D	
1	6	CTC2	FORM	IN	30/03/25		5,43	0,00	.		0,00	51,4	1,5	N/D	
1	7	CTC2	FORM	IN	30/03/25		19,11	0,00	.		0,00	51,4	1,5	N/D	
1	8	CTC2	FORM	IN	30/03/25		1,47	0,00	.		0,00	51,4	1,5	N/D	
Total/Média (3 / 587 · MATA VIRGEM)							78,08	0,00			0,00				

N: 7713853.634
E: 335030.8915
LAT: −20°40'4.1716" (−20.66782545)
LONG: −46°35'2.6806" (−46.58407794)

50.0 0 50.0 100.0
METROS

N
W E
S

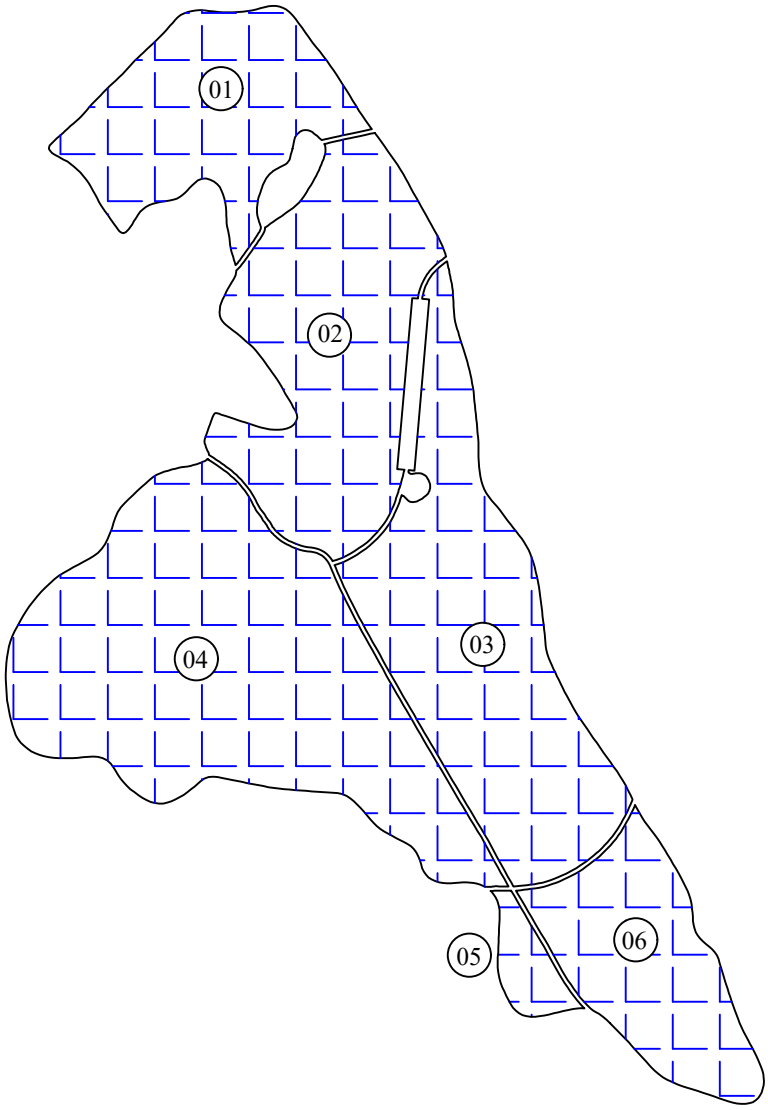

TABELA DE VARIEDADE	
VARIEDADE	ÁREA
CTC2	42,38
Total Geral	**42,38**

CTC - 2

IPIRANGA AGROINDUSTRIAL	PROJETO: CADERNO DE MAPA 25'26	DATA: 13/06/2025	ESCALA: 1:5000	TOPÓGRAFO: CRISTIAN
	FAZENDA: 588 - JOIA DO RIO GRANDE	MUNICÍPIO: DELFINOPOLIS - MG		ÁREA (ha): 42,38
	PROPRIETÁRIO: PAULO RODRIGUES	UNIDADE: IPIRANGA PASSOS S.A.		

Caderno de Mapas

Bloco	Talhao	Variedade	Estágio de Corte	Amb. Prod.	Data Plantio	Último Corte	Área (ha)	Estimativas Área (ha)	Finalid	Produt.	Prod. Total	Dist.	Esp.	Tipo Corte	Experimento
3 · REG 3			**588 · JOIA DO RIO G.**					**PAULO DE ARAUJO RODRIGUES E OUTROS**							
1	1	CTC2	FORM	IN	29/03/25		5,60	0,00	.		0,00	52,4	1,5	N/D	
1	2	CTC2	FORM	IN	22/03/25		8,08	0,00	.		0,00	52,4	1,5	N/D	
1	3	CTC2	FORM	IN	21/03/25		9,47	0,00	.		0,00	52,4	1,5	N/D	
1	4	CTC2	FORM	IN	21/03/25		13,85	0,00	.		0,00	52,4	1,5	N/D	
1	5	CTC2	FORM	IN	15/03/25		0,77	0,00	.		0,00	52,4	1,5	N/D	
1	6	CTC2	FORM	IN	15/03/25		4,61	0,00	.		0,00	52,4	1,5	N/D	
Total/Média (3 / 588 · JOIA DO RIO G.)							42,38	0,00			0,00				

N: 7713853.634
E: 335030.8915
LAT: −20°40'4.1716" (−20.66782545)
LONG: −46°35'2.6806" (−46.58407794)

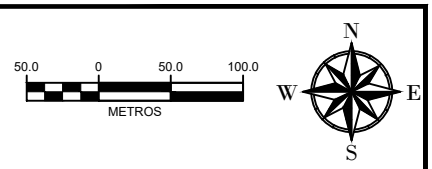

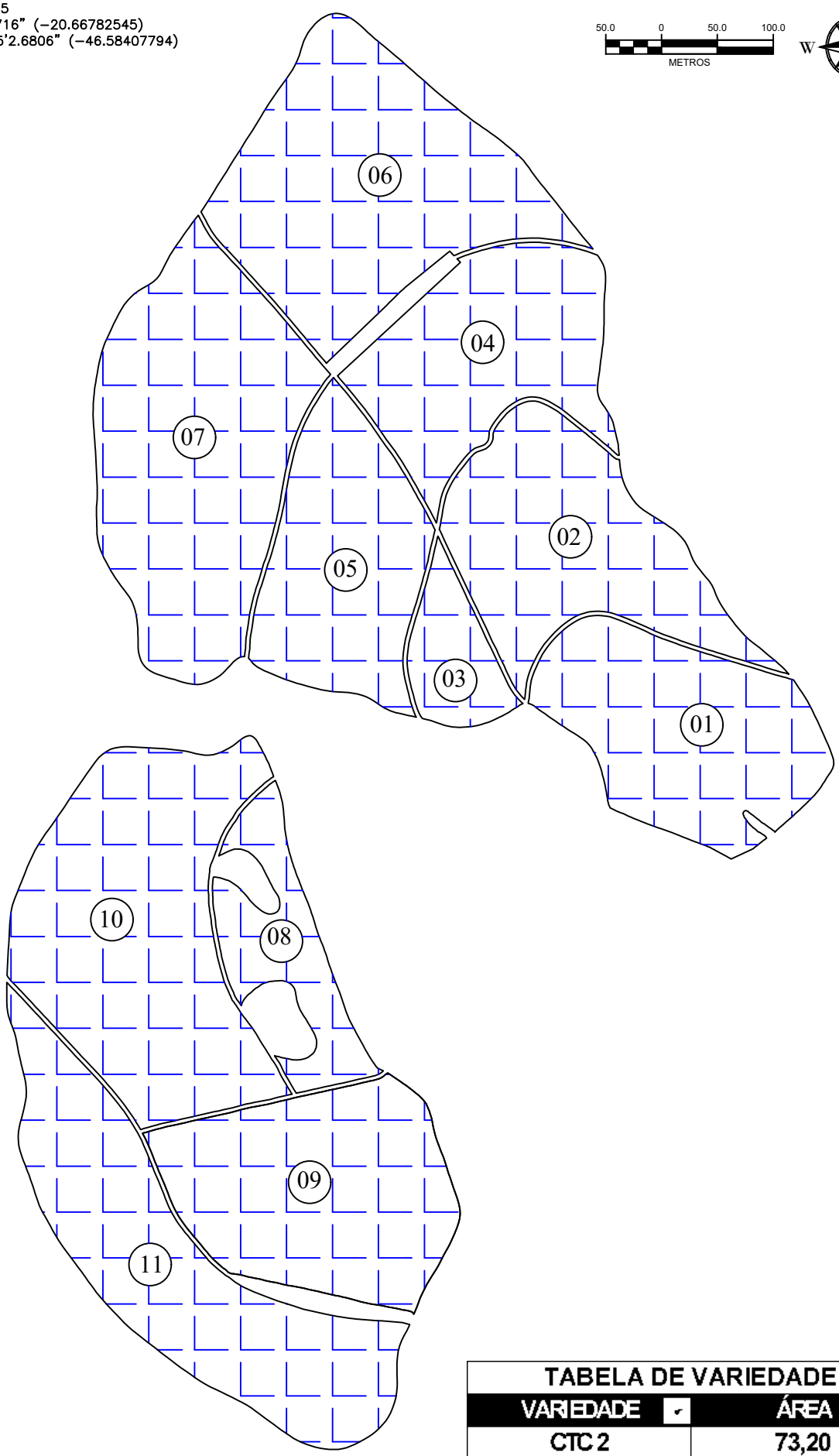

CTC - 2

TABELA DE VARIEDADE	
VARIEDADE	ÁREA
CTC 2	73,20
Total Geral	73,20

IPIRANGA AGROINDUSTRIAL

PROJETO: CADERNO DE MAPA 25'26	DATA: 13/06/2025	ESCALA: 1:5000	TOPÓGRAFO: CRISTIAN
FAZENDA: 589 - ROSA MISTICA	MUNICÍPIO: DELFINOPOLIS - MG		ÁREA (ha): 73,20
PROPRIETÁRIO: PAULO RODRIGUES	UNIDADE: IPIRANGA PASSOS S.A.		

Caderno de Mapas

Bloco	Talhao	Variedade	Estágio de Corte	Amb. Prod.	Data Plantio	Último Corte	Área (ha)	Estimativas Área (ha)	Finalid	Produt.	Prod. Total	Dist.	Esp.	Tipo Corte	Experimento
3 · REG 3			**589 · ROSA MISTICA II**				**PAULO DE ARAUJO RODRIGUES E OUTROS**								
1	1	CTC2	FORM	IN	14/03/25		6,41	0,00	.		0,00	52,6	1,5	N/D	
1	2	CTC2	FORM	IN	14/03/25		6,50	0,00	.		0,00	52,6	1,5	N/D	
1	3	CTC2	FORM	IN	13/03/25		1,66	0,00	.		0,00	52,6	1,5	N/D	
1	4	CTC2	FORM	IN	13/03/25		5,86	0,00	.		0,00	52,6	1,5	N/D	
1	5	CTC2	FORM	IN	12/03/25		5,57	0,00	.		0,00	52,6	1,5	N/D	
1	6	CTC2	FORM	IN	12/03/25		9,21	0,00	.		0,00	52,6	1,5	N/D	
1	7	CTC2	FORM	IN	12/03/25		9,87	0,00	.		0,00	52,6	1,5	N/D	
1	8	CTC2	FORM	IN	11/03/25		2,76	0,00	.		0,00	52,6	1,5	N/D	
1	9	CTC2	FORM	IN	10/03/25		7,25	0,00	.		0,00	52,6	1,5	N/D	
1	10	CTC2	FORM	IN	11/03/25		9,81	0,00	.		0,00	52,6	1,5	N/D	
1	11	CTC2	FORM	IN	10/03/25		8,30	0,00	.		0,00	52,6	1,5	N/D	
Total/Média (3 / 589 · ROSA MISTICA II)							73,20	0,00			0,00				

N: 7713853.634
E: 335030.8915
LAT: −20°40'4.1716" (−20.66782545)
LONG: −46°35'2.6806" (−46.58407794)

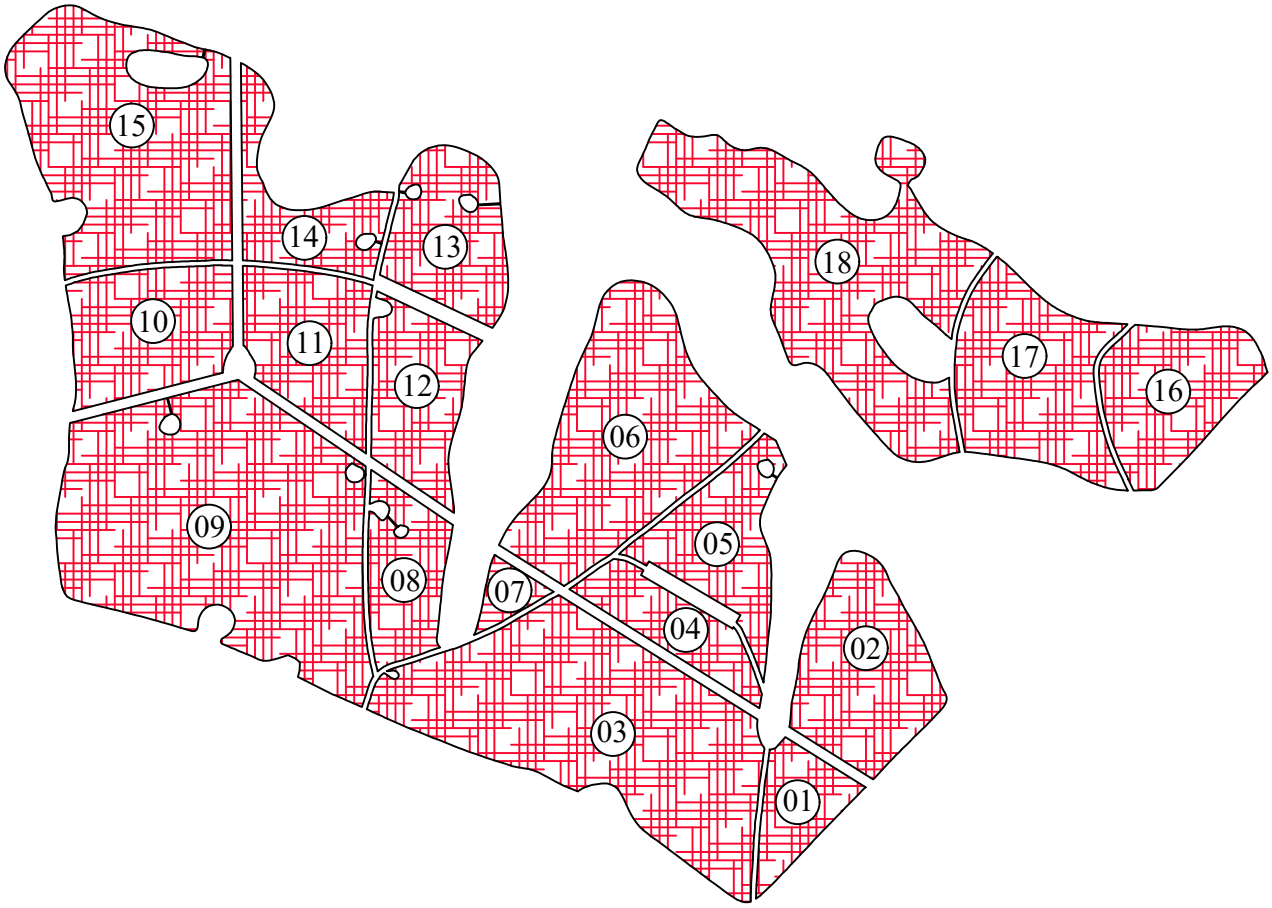

IAC SP 01-5503

TABELA DE VARIEDADE	
VARIEDADE	ÁREA
IAC SP 01-5503	39,70
Total Geral	**39,70**

IPIRANGA AGROINDUSTRIAL

PROJETO: CADERNO DE MAPA 25'26	DATA: 16/06/2025	ESCALA: 1:5000	TOPÓGRAFO: CRISTIAN
FAZENDA: 590 - SANTO ANTONIO_PADEIRINHO	MUNICÍPIO: DELFINOPOLIS - MG		ÁREA (ha): 39,70
PROPRIETÁRIO: PAULO RODRIGUES	UNIDADE: IPIRANGA PASSOS S.A.		

Caderno de Mapas

Bloco	Talhao	Variedade	Estágio de Corte	Amb. Prod.	Data Plantio	Último Corte	Área (ha)	Estimativas Área (ha)	Finalid	Produt.	Prod. Total	Dist.	Esp.	Tipo Corte	Experimento
3 · REG 3			**590 · STO.ANT.PADEIRI**				**PAULO DE ARAUJO RODRIGUES E OUTROS**								
1	1	IACSP01-5503	FORM	IN	16/02/25		0,76	0,00	.		0,00	53,6	1,5	N/D	
1	2	IACSP01-5503	FORM	IN	16/02/25		1,98	0,00	.		0,00	53,6	1,5	N/D	
1	3	IACSP01-5503	FORM	IN	16/02/25		4,98	0,00	.		0,00	53,6	1,5	N/D	
1	4	IACSP01-5503	FORM	IN	15/02/25		0,87	0,00	.		0,00	53,6	1,5	N/D	
1	5	IACSP01-5503	FORM	IN	15/02/25		1,36	0,00	.		0,00	53,6	1,5	N/D	
1	6	IACSP01-5503	FORM	IN	15/02/25		3,33	0,00	.		0,00	53,6	1,5	N/D	
1	7	IACSP01-5503	FORM	IN	15/02/25		0,25	0,00	.		0,00	53,6	1,5	N/D	
1	8	IACSP01-5503	FORM	IN	15/02/25		1,04	0,00	.		0,00	53,6	1,5	N/D	
1	9	IACSP01-5503	FORM	IN	15/02/25		6,14	0,00	.		0,00	53,6	1,5	N/D	
1	10	IACSP01-5503	FORM	IN	14/02/25		1,69	0,00	.		0,00	53,6	1,5	N/D	
1	11	IACSP01-5503	FORM	IN	14/02/25		1,52	0,00	.		0,00	53,6	1,5	N/D	
1	12	IACSP01-5503	FORM	IN	14/02/25		1,34	0,00	.		0,00	53,6	1,5	N/D	
1	13	IACSP01-5503	FORM	IN	13/02/25		1,43	0,00	.		0,00	53,6	1,5	N/D	
1	14	IACSP01-5503	FORM	IN	13/02/25		1,08	0,00	.		0,00	53,6	1,5	N/D	
1	15	IACSP01-5503	FORM	IN	16/02/25		3,85	0,00	.		0,00	53,6	1,5	N/D	
1	16	IACSP01-5503	FORM	IN	16/02/25		1,63	0,00	.		0,00	53,6	1,5	N/D	
1	17	IACSP01-5503	FORM	IN	16/02/25		2,22	0,00	.		0,00	53,6	1,5	N/D	
1	18	IACSP01-5503	FORM	IN	16/02/25		4,23	0,00	.		0,00	53,6	1,5	N/D	
Total/Média (3 / 590 · STO.ANT.PADEIRI)							39,70	0,00			0,00				

N: 7713853.634
E: 335030.8915
LAT: −20°40'4.1716" (−20.66782545)
LONG: −46°35'2.6806" (−46.58407794)

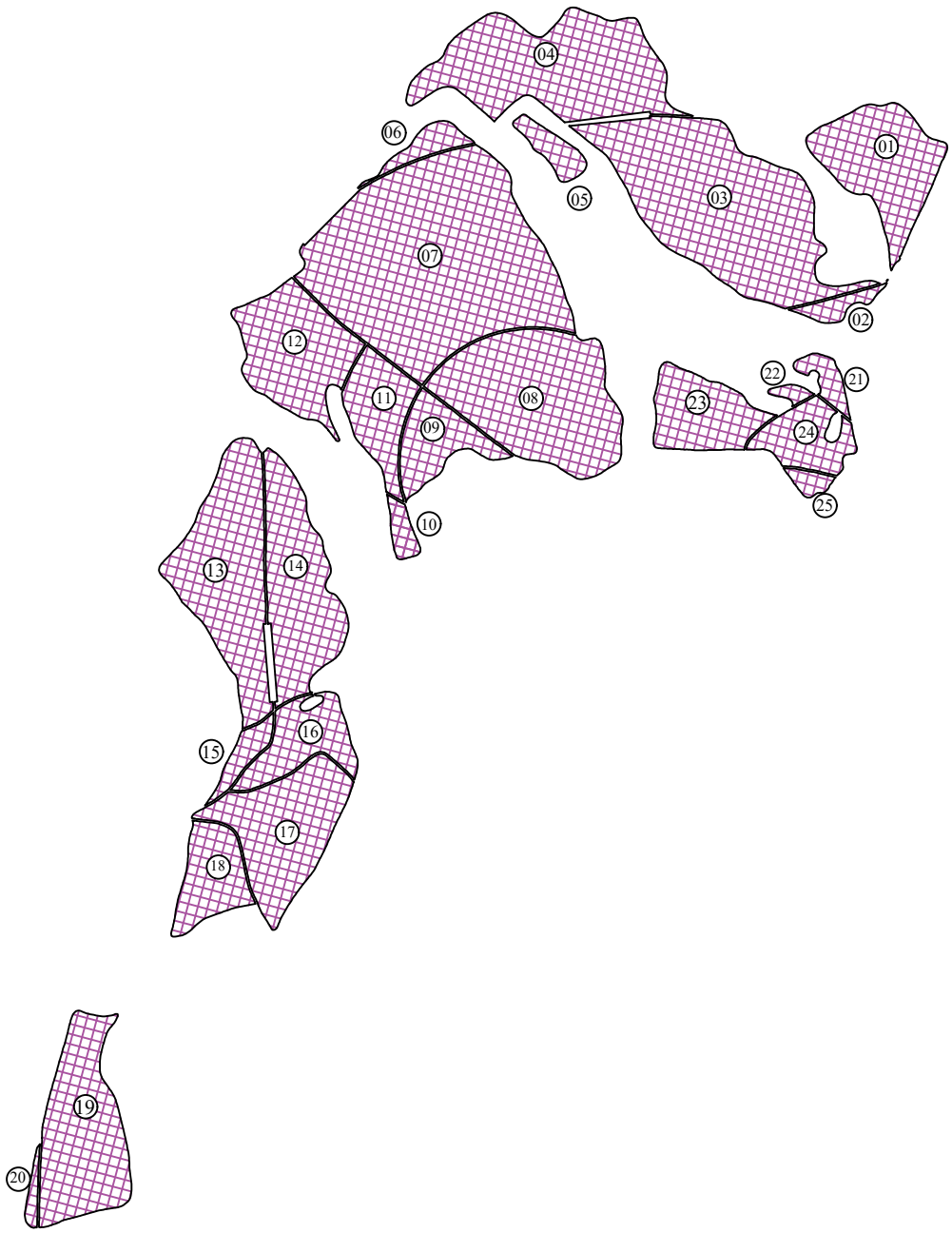

TABELA DE VARIEDADE	
VARIEDADE	ÁREA
IACCTC 07-8008	150,89
Total Geral	150,89

IAC CTC 07-8008

IPIRANGA AGROINDUSTRIAL

PROJETO: CADERNO DE MAPA 25'26	DATA: 13/06/2025	ESCALA: 1:5000	TOPÓGRAFO: CRISTIAN
FAZENDA: 591 - CAMPO REDONDO	MUNICÍPIO: DELFINOPOLIS - MG		ÁREA (ha): 150,89
PROPRIETÁRIO: PAULO RODRIGUES	UNIDADE: IPIRANGA PASSOS S.A.		

Caderno de Mapas

Bloco	Talhao	Variedade	Estágio de Corte	Amb. Prod.	Data Plantio	Último Corte	Área (ha)	Estimativas Área (ha)	Finalid	Produt.	Prod. Total	Dist.	Esp.	Tipo Corte	Experimento
3 · REG 3			**591 · CAMPO REDONDO**				**PAULO DE ARAUJO RODRIGUES E OUTROS**								
1	1	IACCTC07-8008	FORM	IN	27/02/25		7,32	0,00	.		0,00	54,2	1,5	N/D	
1	2	IACCTC07-8008	FORM	IN	27/02/25		0,87	0,00	.		0,00	54,2	1,5	N/D	
1	3	IACCTC07-8008	FORM	IN	27/02/25		17,94	0,00	.		0,00	54,2	1,5	N/D	
1	4	IACCTC07-8008	FORM	IN	27/02/25		13,00	0,00	.		0,00	54,2	1,5	N/D	
1	5	IACCTC07-8008	FORM	IN	27/02/25		1,31	0,00	.		0,00	54,2	1,5	N/D	
1	6	IACCTC07-8008	FORM	IN	27/02/25		1,19	0,00	.		0,00	54,2	1,5	N/D	
1	7	IACCTC07-8008	FORM	IN	27/02/25		25,78	0,00	.		0,00	54,2	1,5	N/D	
1	8	IACCTC07-8008	FORM	IN	27/02/25		12,85	0,00	.		0,00	54,2	1,5	N/D	
1	9	IACCTC07-8008	FORM	IN	27/02/25		3,45	0,00	.		0,00	54,2	1,5	N/D	
1	10	IACCTC07-8008	FORM	IN	27/02/25		0,79	0,00	.		0,00	54,2	1,5	N/D	
1	11	IACCTC07-8008	FORM	IN	27/02/25		3,98	0,00	.		0,00	54,2	1,5	N/D	
1	12	IACCTC07-8008	FORM	IN	27/02/25		7,42	0,00	.		0,00	54,2	1,5	N/D	
1	13	IACCTC07-8008	FORM	IN	27/02/25		10,83	0,00	.		0,00	54,2	1,5	N/D	
1	14	IACCTC07-8008	FORM	IN	27/02/25		8,41	0,00	.		0,00	54,2	1,5	N/D	
1	15	IACCTC07-8008	FORM	IN	27/02/25		1,13	0,00	.		0,00	54,2	1,5	N/D	
1	16	IACCTC07-8008	FORM	IN	27/02/25		3,80	0,00	.		0,00	54,2	1,5	N/D	
1	17	IACCTC07-8008	FORM	IN	27/02/25		8,10	0,00	.		0,00	54,2	1,5	N/D	
1	18	IACCTC07-8008	FORM	IN	27/02/25		3,72	0,00	.		0,00	54,2	1,5	N/D	
1	19	IACCTC07-8008	FORM	IN	27/02/25		8,94	0,00	.		0,00	54,2	1,5	N/D	
1	20	IACCTC07-8008	FORM	IN	27/02/25		0,42	0,00	.		0,00	54,2	1,5	N/D	
1	21	IACCTC07-8008	FORM	IN	27/02/25		1,00	0,00	.		0,00	54,2	1,5	N/D	
1	22	IACCTC07-8008	FORM	IN	27/02/25		0,33	0,00	.		0,00	54,2	1,5	N/D	
1	23	IACCTC07-8008	FORM	IN	27/02/25		4,60	0,00	.		0,00	54,2	1,5	N/D	
1	24	IACCTC07-8008	FORM	IN	27/02/25		3,16	0,00	.		0,00	54,2	1,5	N/D	
1	25	IACCTC07-8008	FORM	IN	27/02/25		0,55	0,00	.		0,00	54,2	1,5	N/D	
Total/Média (3 / 591 · CAMPO REDONDO)							150,89	0,00			0,00				

N: 7713853.634
E: 335030.8915
LAT: −20°40'4.1716" (−20.66782545)
LONG: −46°35'2.6806" (−46.58407794)

50.0 0 50.0 100.0
METROS

N
W E
S

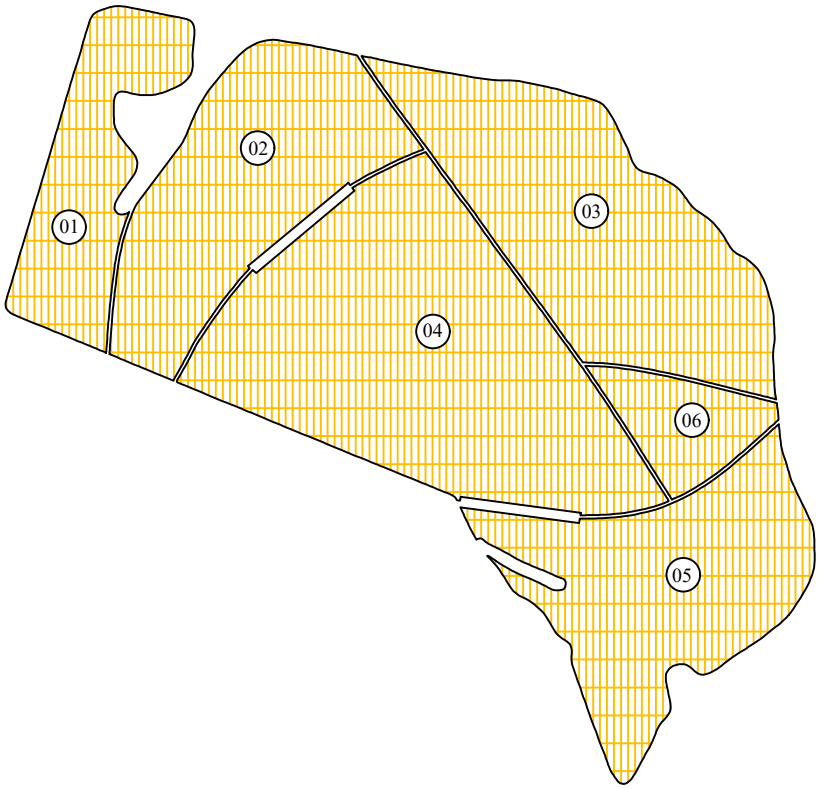

TABELA DE VARIEDADE	
VARIEDADE	ÁREA
RB 98-5476	67,16
Total Geral	**67,16**

RB 98-5476

IPIRANGA AGROINDUSTRIAL

PROJETO: CADERNO DE MAPA 25'26	DATA: 13/06/2025	ESCALA: 1:5000	TOPÓGRAFO: CRISTIAN
FAZENDA: 592 - SAO SEBASTIAO - JACI	MUNICÍPIO: DELFINOPOLIS - MG		ÁREA (ha): 67,16
PROPRIETÁRIO: PAULO RODRIGUES	UNIDADE: IPIRANGA PASSOS S.A.		

Caderno de Mapas

Bloco	Talhao	Variedade	Estágio de Corte	Amb. Prod.	Data Plantio	Último Corte	Área (ha)	Estimativas Área (ha)	Finalid	Produt.	Prod. Total	Dist.	Esp.	Tipo Corte	Experimento
3 · REG 3			**592 · S.SEBASTIAO JAC**				**PAULO DE ARAUJO RODRIGUES E OUTROS**								
1	1	RB985476	FORM	IN	23/01/25		6,52	0,00	.		0,00	46,3	1,5	N/D	
1	2	RB985476	FORM	IN	23/01/25		11,07	0,00	.		0,00	46,3	1,5	N/D	
1	3	RB985476	FORM	IN	22/01/25		14,36	0,00	.		0,00	46,3	1,5	N/D	
1	4	RB985476	FORM	IN	21/01/25		20,48	0,00	.		0,00	46,3	1,5	N/D	
1	5	RB985476	FORM	IN	20/01/25		11,81	0,00	.		0,00	46,3	1,5	N/D	
1	6	RB985476	FORM	IN	22/01/25		2,92	0,00	.		0,00	46,3	1,5	N/D	
Total/Média (3 / 592 · S.SEBASTIAO JAC)							67,16	0,00			0,00				

N: 7708979.482
E: 347783.4128
LAT: −20°42'46.5647" (−20.71293464)
LONG: −46°27'43.5863" (−46.46210731)

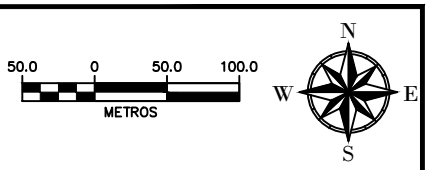

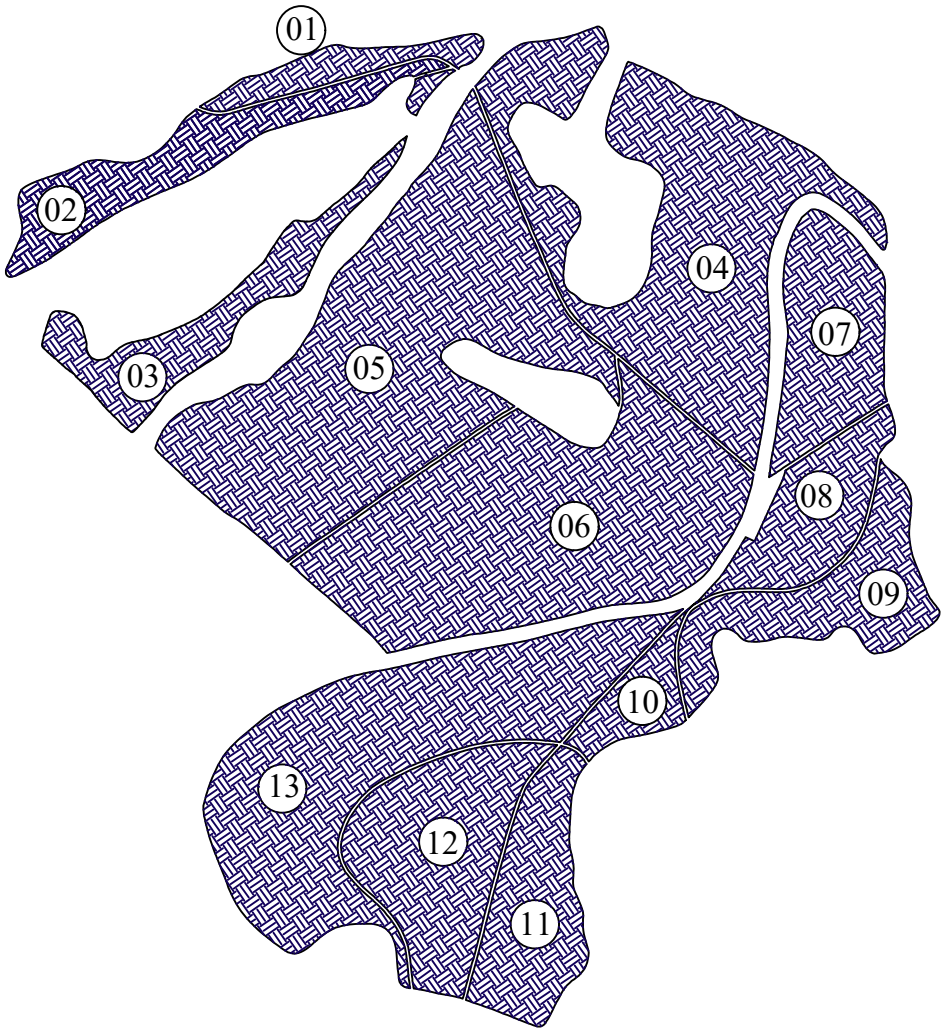

CTC - 9006

TABELA DE VARIEDADE	
VARIEDADE	ÁREA
CTC9006	91,19
Total Geral	**91,19**

IPIRANGA AGROINDUSTRIAL	PROJETO: CADERNO DE MAPA 25´26	DATA: 22-07-2025 / ESCALA: 1:5000	TOPÓGRAFO: CRISTIAN
	FAZENDA: 593 - SANTA MARIA/SANTA LUCIA	MUNICÍPIO: PASSOS - MG	ÁREA (ha): 91,19
	PROPRIETÁRIO: MARCOS TADEU	UNIDADE: IPIRANGA PASSOS - MG	CÓDIGO: 593

Caderno de Mapas

Bloco	Talhao	Variedade	Estágio de Corte	Amb. Prod.	Data Plantio	Último Corte	Área (ha)	Estimativas Área (ha)	Finalid	Produt.	Prod. Total	Dist.	Esp.	Tipo Corte	Experimento
3 · REG 3			**593 · STA.MARIA/STA.L**					**MARCOS TADEU MIRANDA CARVALHO**							
1	1	CTC9006	FORM	NC	07/02/25		1,45	0,00	.		0,00	52	1,5	N/D	
1	2	CTC9006	FORM	NC	10/02/25		4,04	0,00	.		0,00	52	1,5	N/D	
1	3	CTC9006	FORM	NC	10/02/25		3,61	0,00	.		0,00	52	1,5	N/D	
1	4	CTC9006	FORM	NC	13/02/25		13,37	0,00	.		0,00	52	1,5	N/D	
1	5	CTC9006	FORM	NC	11/02/25		17,28	0,00	.		0,00	52	1,5	N/D	
1	6	CTC9006	FORM	NC	09/02/25		15,15	0,00	.		0,00	52	1,5	N/D	
1	7	CTC9006	FORM	NC	13/02/25		4,40	0,00	.		0,00	52	1,5	N/D	
1	8	CTC9006	FORM	NC	13/02/25		3,25	0,00	.		0,00	52	1,5	N/D	
1	9	CTC9006	FORM	NC	30/01/25		4,27	0,00	.		0,00	52	1,5	N/D	
1	10	CTC9006	FORM	NC	11/02/25		1,50	0,00	.		0,00	52	1,5	N/D	
1	11	CTC9006	FORM	NC	07/02/25		4,26	0,00	.		0,00	52	1,5	N/D	
1	12	CTC9006	FORM	NC	29/01/25		6,09	0,00	.		0,00	52	1,5	N/D	
1	13	CTC9006	FORM	NC	12/02/25		12,52	0,00	.		0,00	52	1,5	N/D	
Total/Média (3 / 593 · STA.MARIA/STA.L)							91,19	0,00			0,00				

N: 7708979.482
E: 347783.4128
LAT: −20°42'46.5647" (−20.71293464)
LONG: −46°27'43.5863" (−46.46210731)

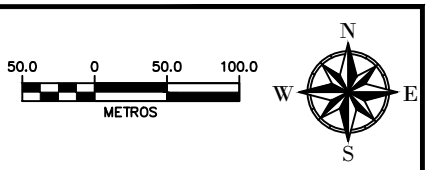

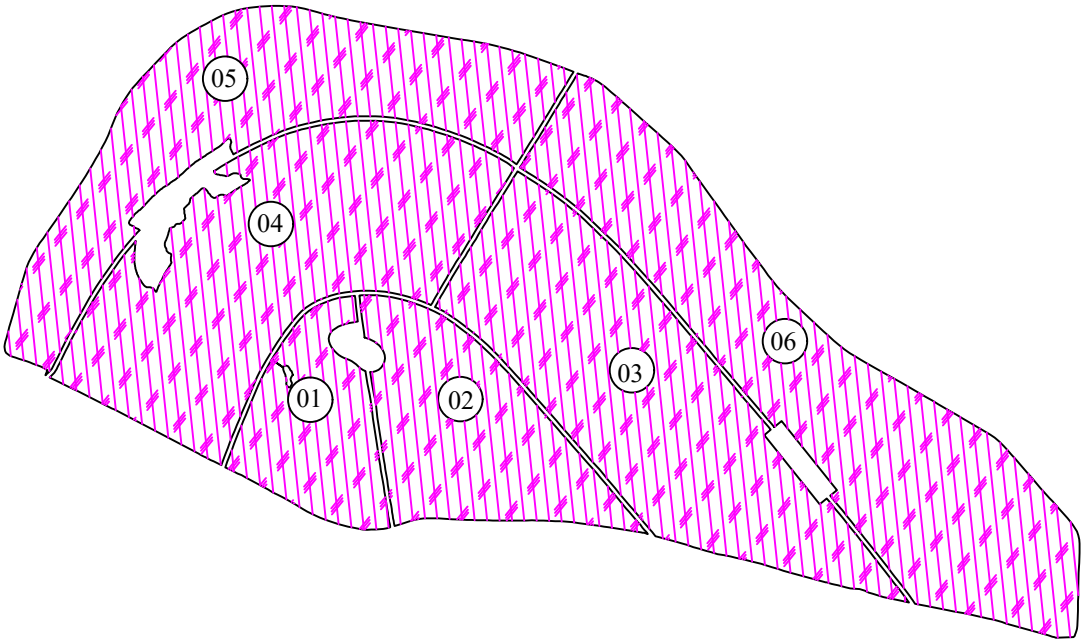

CTC -2994

TABELA DE VARIEDADE	
VARIEDADE	ÁREA
CTC2994	44,46
Total Geral	**44,46**

IPIRANGA AGROINDUSTRIAL	PROJETO: CADERNO DE MAPA 25'26	DATA: 21/03/2025	ESCALA: 1:5000	TOPÓGRAFO: LUÍS DUARTE
	FAZENDA: 595 - MARINHEIRO	MUNICÍPIO: PASSOS - MG		ÁREA (ha): 44,46
	PROPRIETÁRIO: YURI PEREIRA DA SILVA	UNIDADE: IPIRANGA PASSOS - MG		CÓDIGO: 595

Caderno de Mapas

Bloco	Talhao	Variedade	Estágio de Corte	Amb. Prod.	Data Plantio	Último Corte	Área (ha)	Estimativas Área (ha)	Finalid	Produt.	Prod. Total	Dist.	Esp.	Tipo Corte	Experimento
3 · REG 3			**595 · MARINHEIRO**				**YURI PEREIRA DA SILVEIRA**								
1	1	CTC2994	FORM	NC	10/03/25		2,86	0,00	.		0,00	31,7	1,5	N/D	
1	2	CTC2994	FORM	NC	10/03/25		4,56	0,00	.		0,00	31,7	1,5	N/D	
1	3	CTC2994	FORM	NC	11/03/25		9,00	0,00	.		0,00	31,7	1,5	N/D	
1	4	CTC2994	FORM	NC	12/03/25		9,39	0,00	.		0,00	31,7	1,5	N/D	
1	5	CTC2994	FORM	NC	13/03/25		7,86	0,00	.		0,00	31,7	1,5	N/D	
1	6	CTC2994	FORM	NC	13/03/25		10,79	0,00	.		0,00	31,7	1,5	N/D	
Total/Média (3 / 595 · MARINHEIRO)							44,46	0,00			0,00				

N: 7708979.482
E: 347783.4128
LAT: −20°42'46.5647" (−20.71293464)
LONG: −46°27'43.5863" (−46.46210731)

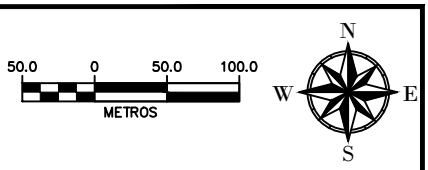

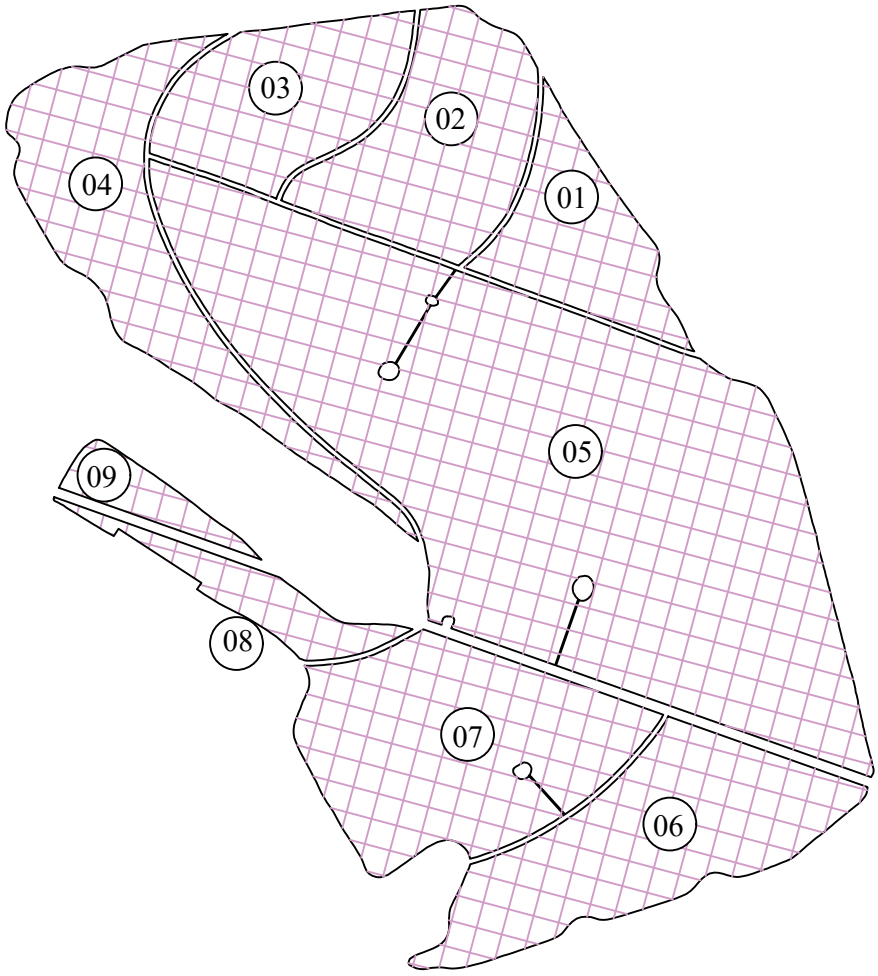

IAC CTC 07-7207

TABELA DE VARIEDADE	
VARIEDADE	ÁREA
IACCTC07-7207	41,42
Total Geral	**41,42**

PROJETO: CADERNO DE MAPA 25'26	DATA: 14/03/2025	ESCALA: 1:5000	TOPÓGRAFO: LUÍS DUARTE
FAZENDA: 596 - SANTA MARIA V	MUNICÍPIO: PASSOS - MG		ÁREA (ha): 41,42
PROPRIETÁRIO: GABRIEL RODRIGUES FERREIRA	UNIDADE: IPIRANGA PASSOS - MG		CÓDIGO:

IPIRANGA AGROINDUSTRIAL

Caderno de Mapas

Bloco	Talhao	Variedade	Estágio de Corte	Amb. Prod.	Data Plantio	Último Corte	Área (ha)	Estimativas Área (ha)	Finalid	Produt.	Prod. Total	Dist.	Esp.	Tipo Corte	Experimento
3 · REG 3			**596 · STA.MARIA V**				**GABRIEL RODRIGUES FERREIRA**								
1	1	IACCTC07-7207	FORM	NC	08/03/25		2,15	0,00	.		0,00	10,7	1,5	N/D	
1	2	IACCTC07-7207	FORM	NC	08/03/25		3,38	0,00	.		0,00	10,7	1,5	N/D	
1	3	IACCTC07-7207	FORM	NC	09/03/25		2,85	0,00	.		0,00	10,7	1,5	N/D	
1	4	IACCTC07-7207	FORM	NC	09/03/25		3,97	0,00	.		0,00	10,7	1,5	N/D	
1	5	IACCTC07-7207	FORM	NC	08/03/25		17,79	0,00	.		0,00	10,7	1,5	N/D	
1	6	IACCTC07-7207	FORM	NC	09/03/25		4,41	0,00	.		0,00	10,7	1,5	N/D	
1	7	IACCTC07-7207	FORM	NC	09/03/25		5,15	0,00	.		0,00	10,7	1,5	N/D	
1	8	IACCTC07-7207	FORM	NC	09/03/25		1,05	0,00	.		0,00	10,7	1,5	N/D	
1	9	IACCTC07-7207	FORM	NC	09/03/25		0,67	0,00	.		0,00	10,7	1,5	N/D	
Total/Média (3 / 596 · STA.MARIA V)							41,42	0,00			0,00				

N: 7713853.634
E: 335030.8915
LAT: −20°40'4.1716" (−20.66782545)
LONG: −46°35'2.6806" (−46.58407794)

50.0 0 50.0 100.0
METROS

N
W E
S

CONTROLE

- CADASTRO
- TRANSFERÊNCIA

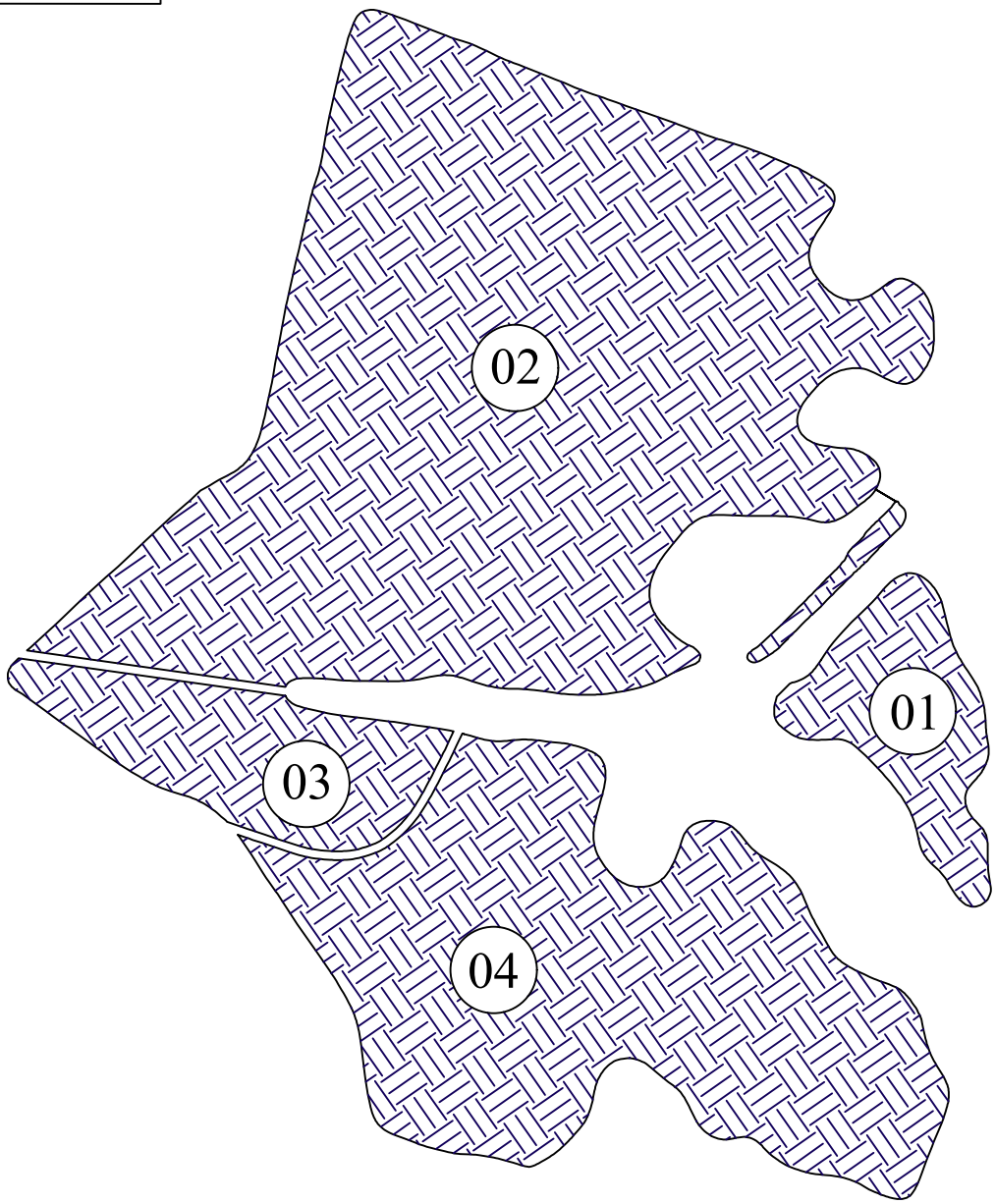

TABELA DE VARIEDADE

VARIEDADE	ÁREA
CTC9006	19,52
Total Geral	**19,52**

CTC - 9006

IPIRANGA AGROINDUSTRIAL

PROJETO	DATA	ESCALA	TOPÓGRAFO
CADERNO DE MAPA 25'26	01/08/2025	1:5000	LUIS DUARTE
FAZENDA	**MUNICÍPIO**		**ÁREA (ha)**
597 - MANDIOCA	DELFINOPOLIS		19,52
PROPRIETÁRIO	**UNIDADE**		
RAUL	IPIRANGA PASSOS S.A.		

Caderno de Mapas

Bloco	Talhao	Variedade	Estágio de Corte	Amb. Prod.	Data Plantio	Último Corte	Área (ha)	Estimativas Área (ha)	Finalid	Produt.	Prod. Total	Dist.	Esp.	Tipo Corte	Experimento
3 · REG 3			**597 · MANDIOCA**				**RAUL MEDEIROS CINTRA E OUTROS**								
1	1	CTC9006	FORM	NC	25/02/25		1,12	0,00	.		0,00	50	1,5	N/D	
1	2	CTC9006	FORM	NC	26/02/25		11,13	0,00	.		0,00	50	1,5	N/D	
1	3	CTC9006	FORM	NC	25/02/25		1,46	0,00	.		0,00	50	1,5	N/D	
1	4	CTC9006	FORM	NC	25/02/25		5,81	0,00	.		0,00	50	1,5	N/D	
Total/Média (3 / 597 · MANDIOCA)							19,52	0,00			0,00				

N: 7713853.634
E: 335030.8915
LAT: −20°40'4.1716" (−20.66782545)
LONG: −46°35'2.6806" (−46.58407794)

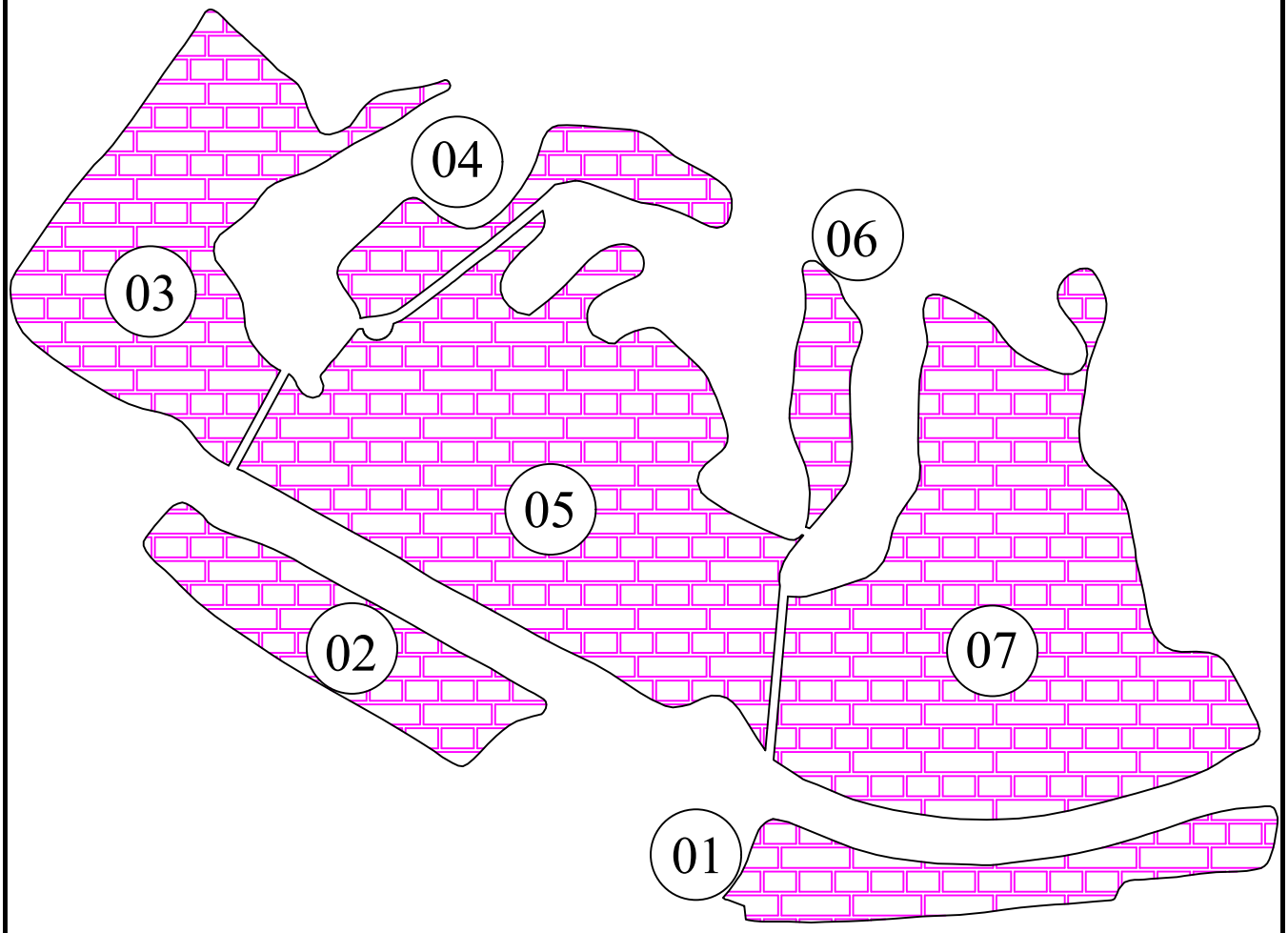

RB 97-5375

TABELA DE VARIEDADE	
VARIEDADE	ÁREA
RB975375	14,34
Total Geral	**14,34**

IPIRANGA AGROINDUSTRIAL	PROJETO: CADERNO DE MAPA 25'26	DATA: 13/03/2025	ESCALA: 1:5000	TOPÓGRAFO: LUIS DUARTE
	FAZENDA: 598 - BELA VISTA II	MUNICÍPIO: PASSOS - MG	ÁREA (ha): 14,34
	PROPRIETÁRIO:	UNIDADE: IPIRANGA PASSOS S.A.	

Caderno de Mapas

Bloco	Talhao	Variedade	Estágio de Corte	Amb. Prod.	Data Plantio	Último Corte	Área (ha)	Estimativas Área (ha)	Finalid	Produt.	Prod. Total	Dist.	Esp.	Tipo Corte	Experimento
3 · REG 3			**598 · BELA VISTA II**				**JOSE IVALDO RODRIGUES NETO E OUTRO(S)**								
1	1	RB975375	FORM	NC	31/03/25		1,00	0,00	.		0,00	34	1,5	N/D	
1	2	RB975375	FORM	NC	31/03/25		1,12	0,00	.		0,00	34	1,5	N/D	
1	3	RB975375	FORM	NC	31/03/25		2,33	0,00	.		0,00	34	1,5	N/D	
1	4	RB975375	FORM	NC	31/03/25		0,68	0,00	.		0,00	34	1,5	N/D	
1	5	RB975375	FORM	NC	31/03/25		4,40	0,00	.		0,00	34	1,5	N/D	
1	6	RB975375	FORM	NC	31/03/25		0,37	0,00	.		0,00	34	1,5	N/D	
1	7	RB975375	FORM	NC	31/03/25		4,44	0,00	.		0,00	34	1,5	N/D	
Total/Média (3 / 598 · BELA VISTA II)							14,34	0,00			0,00				