CADERNO DE MAPA – SAFRA 26'27
UNIDADE PASSOS

IPIRANGA
AGROINDUSTRIAL

UNIDADE MOCOCA

Rodovia SP 338, Km 287, s/n
Fazenda Santa Emília, Mococa - SP
CEP: 13730-971

+55 (019) 3666-7000

UNIDADE DESCALVADO

Estrada Municipal Guilherme Scatena,
s/n - Zona Rural, Descalvado - SP
CEP: 13690-000

+55 (019) 3590-1000

UNIDADE IACANGA

Rod. Cezário José de Castilho, Fazenda
Nova, s/n – Zona Rural, Iacanga – SP
CEP: 17180-000

+55 (014) 3294-9000

UNIDADE PASSOS

Rod. MGC 146, Dep. Humberto de Almeida,
s/n, Faz. Soledade, Zona Rural, Passos – MG
CEP: 37900-970

LISTAGEM DE FAZENDA				
CODIGO	DESCRIÇÃO	MUNICÍPIO	ÁREA	DISTÂNCIA
1	ALGODAO	PASSOS	17,16	6,00
2	CACHOEIRA TAQUARUÇU	PASSOS	33,26	14,00
3	NOVA SOLEDADE	PASSOS	434,73	4,00
4	POÇO	PASSOS	326,36	11,00
5	SANTA ESMERIA	PASSOS	276,33	6,00
6	SANTA TEREZA	PASSOS	287,90	6,00
7	SANTO ANTONIO I	PASSOS	111,82	9,00
8	SAO DOMINGOS	PASSOS	12,71	10,00
9	SAO GERALDO	PASSOS	148,97	8,50
10	SAO JOAQUIM	PASSOS	16,86	11,30
11	SAO JOSE	PASSOS	402,27	8,30
12	SAO PEDRO	PASSOS	331,39	9,00
13	SAO VICENTE	PASSOS	63,45	5,80
14	SITIO NINFAS	PASSOS	63,16	21,00
15	SITIO SANTA TEREZA	PASSOS	9,98	6,00
16	SOLEDADE	PASSOS	55,70	3,00
17	SOLEDADE I	PASSOS	101,66	3,00
18	SOLEDADE II	PASSOS	422,78	5,00
19	TAQUARUÇU	PASSOS	613,79	12,00
20	TRES ILHAS	PASSOS	298,53	8,20
21	ARADINHO	PASSOS	276,70	25,30
22	FAZENDA VIRADOURO	PASSOS	4,30	25,70
23	BARRA BOCAINA	PASSOS	307,19	21,40
24	BARRA DOCE I	PASSOS	80,19	30,30
25	BARRINHA I	PASSOS	20,56	29,80
26	BOA VISTA	PASSOS	967,28	35,00
27	CAETES	PASSOS	70,24	31,20
28	CANOAS	PASSOS	147,84	33,70
29	COQUEIRINHO	PASSOS	30,51	31,20
30	COQUEIROS	PASSOS	233,87	33,60
31	ESTANCIA	PASSOS	156,00	31,00
32	MANGUEIRA	PASSOS	544,07	27,00
33	MARRECAS	PASSOS	268,61	36,20
35	RIO GRANDE	PASSOS	30,33	24,10
37	SANTO ANTONIO BOA VISTA	PASSOS	81,81	34,20
38	SANTO ANTONIO BOCAINA	PASSOS	264,75	20,40
39	VARGINHA	PASSOS	342,21	34,20
40	VIRADOURO	PASSOS	275,17	27,90
41	BELA VISTA	PASSOS	462,46	33,40
42	MONJOLINHO	SAO JOSE DA BARRA	256,84	41,00
43	NOSSA SENHORA DO CARMO	ALPINOPOLIS	367,35	29,00
44	PONTA DA SERRA	SAO JOSE DA BARRA	245,89	41,00
45	SAO SEBASTIAO TAQUARUÇU	PASSOS	50,89	16,60
46	SITIO TRES BARRAS	PASSOS	76,64	26,00
47	SITIO BARRA TRES LAGOAS	ALPINOPOLIS	32,48	27,20
48	SITIO NOSSA SENHORA DO CARMO	ALPINOPOLIS	40,25	26,40
49	SITIO PE DA SERRA	SAO JOSE DA BARRA	30,24	39,40
50	SITIO SAO BENTO	ALPINOPOLIS	17,47	30,00
51	SITIO TRES LAGOAS	ALPINOPOLIS	15,76	28,20
52	TRES BARRAS	PASSOS	353,12	27,00
53	TRES LAGOAS	ALPINOPOLIS	384,91	30,60
54	VERA CRUZ	PASSOS	154,45	23,00
60	BATATAIS	PASSOS	43,52	23,00
62	TAGUAUNA I	PASSOS	194,39	26,00
66	SERRINHA	PASSOS	14,27	11,90
67	SAO SEBASTIAO	PASSOS	54,87	18,00
69	BARRINHA II	PASSOS	40,98	29,00
70	SAO JOSE BOCAINA	PASSOS	39,07	16,00
71	BARRA DOCE II	PASSOS	51,71	28,00
73	NINFAS	PASSOS	47,59	20,00
76	SAO BARTOLOMEU / NINFAS	PASSOS	26,12	20,60
94	RANCHAO V	DELFINOPOLIS	25,83	26,00
102	SANTO ANTONIO II	PASSOS	40,15	17,30
103	SOLEDADE IV	PASSOS	21,48	6,60
104	SANTA PAULA	PASSOS	28,96	37,00
105	BALSAMO	PASSOS	14,60	41,00
106	LIMEIRA	PASSOS	23,67	41,00
107	PALMITAL	PASSOS	51,31	50,60
108	CRIMEIA/LIMEIRA III	PASSOS	5,54	9,50
111	SITIO TRES BARRAS B	PASSOS	83,01	27,00
112	BARREIRO	PASSOS	26,67	32,00
113	PONTE GRANDE 1	PASSOS	24,15	36,00
114	PONTE GRANDE 2	PASSOS	28,79	37,00
115	VISTA NOBRE	PASSOS	39,82	15,00
117	BOM JARDIM	DELFINOPOLIS	785,48	62,00
118	TAQUARUSSU II	PASSOS	4,53	16,00
119	GROTÃO	PASSOS	11,50	20,20
120	SAO JOSE DA BOCAINA II	PASSOS	29,28	14,00
121	BARRINHA III	PASSOS	19,64	31,00
122	ESTIVA II	PASSOS	20,03	28,00
123	SANTO ANTONIO III	PASSOS	68,21	15,00
124	CRIMEIA II	PASSOS	5,59	9,30
125	CAMPO REDONDO	DELFINOPOLIS	80,99	54,00
126	SANTA IZAURA	DELFINOPOLIS	92,82	50,80
127	BARRA DOCE III	PASSOS	4,41	25,00
128	ESTIVA III	DELFINOPOLIS	47,93	55,00
129	SAO SEBASTIAO IV	PASSOS	56,40	16,80
130	SANTO REY II	PASSOS	101,72	39,00
131	SANTO REY III	PASSOS	92,02	40,00
132	GOULART	SAO JOAO BATISTA GLORIA	100,98	11,00
133	SANTO REY I	PASSOS	112,21	38,00
134	SANTO REY IV	PASSOS	110,63	42,00
135	BRAGANÇA	PASSOS	66,08	31,00
136	SAO JOAO DA BOCAINA	PASSOS	48,19	16,50
137	CAVAQUINHO	DELFINOPOLIS	51,32	50,00

PASSOS

Safra: 2026 / 2027
Data: 26/05/26
Hora: 14:50:49

Censo Varietal por Estágio de Corte
Área em (ha)

VARIEDADE	Cana Bis	Expansão	Reforma	Formação	Cana de Ano	Cana de Ano e Meio	Segundo Corte	Terceiro Corte	Quarto Corte	Quinto Corte +	1 Inverno	Muda	TOTAL	%
A DEFINIR	0	51,90	84,99	0	0	0	0	0	0	0	0	0,00	136,89	1,01
CTC2	0	0	0	102,83	0	68,89	241,10	422,98	446,80	198,07	0	31,76	1.512,43	11,20
CTC2519	0	0	0	76,26	0	0	0	0	0	0	0	0,00	76,26	0,56
CTC2994	0	0	0	238,63	0,00	105,16	414,32	730,50	67,97	3,22	101,25	122,58	1.783,63	13,21
CTC3445	0	0	0	30,10	0	25,69	10,97	0	0	0	0	0,00	66,76	0,49
CTC4	0	0	0	0	0	58,76	0,05	172,19	1.546,87	455,68	0	0,23	2.233,78	16,54
CTC9001	0	0	0	0	0	0	0	0	144,68	6,66	0	0,00	151,34	1,12
CTC9001BT	0	0	0	0	0	0	2,50	0	0	0	0	0,00	2,50	0,02
CTC9002	0	0	0	0	0	0	0	0	154,80	0	0	0,00	154,80	1,15
CTC9003	0	0	0	0	0	0	159,42	203,33	141,07	0	0	0,00	503,82	3,73
CTC9003BT	0	0	0	0	0	0	4,47	0	0	0	0	0,00	4,47	0,03
CTC9006	0	0	0	559,19	0	17,91	67,63	136,94	23,31	0	0	94,82	899,80	6,66
CTC9007	0	0	0	0	0	12,37	33,79	202,61	44,91	0	0	31,76	325,44	2,41
CTC9008	0	0	0	203,28	0	13,96	20,55	2,28	0	0	0	22,26	262,33	1,94
CTC9009	0	0	0	0	0	32,96	28,14	0,67	0	0	0	0,00	61,77	0,46
CTC9011	0	0	0	5,44	0	0	0	0	0	0	0	0,00	5,44	0,04
CV7870	0	0	0	0	0	0	0	61,95	0	0	0	0,00	61,95	0,46
IACCTC07-7207	0	0	0	36,36	0	233,45	63,14	52,17	10,40	0	0	7,37	402,89	2,98
IACCTC07-8008	0	0	0	0	0	51,11	163,88	0	140,16	6,07	0	0,00	361,22	2,68
IACSP01-5503	0	0	0	295,99	0	130,04	148,68	345,45	66,44	11,73	0	77,44	1.075,77	7,97
IACSP02-1064	0	0	0	0	0	0	20,22	0	0	0	0	0,00	20,22	0,15
IACSP04-6007	0	0	0	0	0	0	0	20,76	0	0	0	0,00	20,76	0,15
IACSP95-5094	0	0	0	0	0	0	0	61,81	140,44	0	0	0,00	202,25	1,50
RB005014	0	0	0	0	0	0	10,22	0	15,53	0	0	0,00	25,75	0,19
RB015177	0	0	0	0	0	0	0	33,85	0	0	0	0,00	33,85	0,25
RB075253	0	0	0	0	0	1,48	0	0	0	0	0	0,26	1,74	0,01

Censo Varietal por Estágio de Corte
Área em (ha)

VARIEDADE	Cana Bis	Expansão	Reforma	Formação	Cana de Ano	Cana de Ano e Meio	Segundo Corte	Terceiro Corte	Quarto Corte	Quinto Corte +	1 Inverno	Muda	TOTAL	%
RB075322	0	0	0	6,24	0	0	0,58	0	0	0	0	1,16	7,98	0,06
RB127825	0	0	0	32,60	0	31,39	22,42	12,99	1,41	0	8,79	4,71	114,31	0,85
RB855156	0	0	0	0	0	0	0	0	44,20	0	0	0,00	44,20	0,33
RB855453	0	0	0	0	0	0	0	0	17,88	0	0	0,00	17,88	0,13
RB867515	0	0	0	0	0	0	0	75,35	0	0	0	0,00	75,35	0,56
RB928064	0	0	0	0	0	4,91	2,37	0	1,13	0	0	0,00	8,41	0,06
RB966928	0	0	0	0	0	0	0	100,65	812,18	171,24	0	0,00	1.084,07	8,03
RB975375	0	0	0	6,22	0	21,37	0	18,85	0	0	0	1,34	47,78	0,35
RB975952	0	0	0	0	0	0	0	89,46	59,33	48,25	0	0,00	197,04	1,46
RB985476	0	0	0	0	0	0	88,33	104,56	60,93	0	0	0,00	253,82	1,88
RB987935	0	0	0	0	0	0	4,53	244,52	499,91	81,34	0	0,00	830,30	6,15
RB988082	0	0	0	0	0	0	0	12,76	119,57	43,55	0	0,00	175,88	1,30
RB991532	0	0	0	0,74	0	0	0	0	0	0	0	0,00	0,74	0,01
SP80-1816	0	0	0	0	0	0	0	0	190,49	0	0	0,00	190,49	1,41
VIVEIRO	0	0	0	38,96	0	6,20	2,20	0,23	17,67	0	0,07	1,09	66,42	0,49
Total	0,00	51,90	84,99	1.632,84	0,00	815,65	1.509,51	3.106,86	4.768,08	1.025,81	110,11	396,78	13502,53	100,00
%	0,00	0,38	0,63	12,09	0,00	6,04	11,18	23,01	35,31	7,60	0,82	2,94	100,00	100,00

O que são Áreas de Preservação Permanente ou APP?

Áreas de Preservação Permanente são áreas, cobertas ou não por vegetação nativa, localizadas na zona rural ou urbana, com a função ambiental de preservar os recursos hídricos, a paisagem, a estabilidade geológica e a biodiversidade, facilitar o fluxo gênico de fauna e flora,proteger o solo e assegurar o bem-estar das populações humanas.

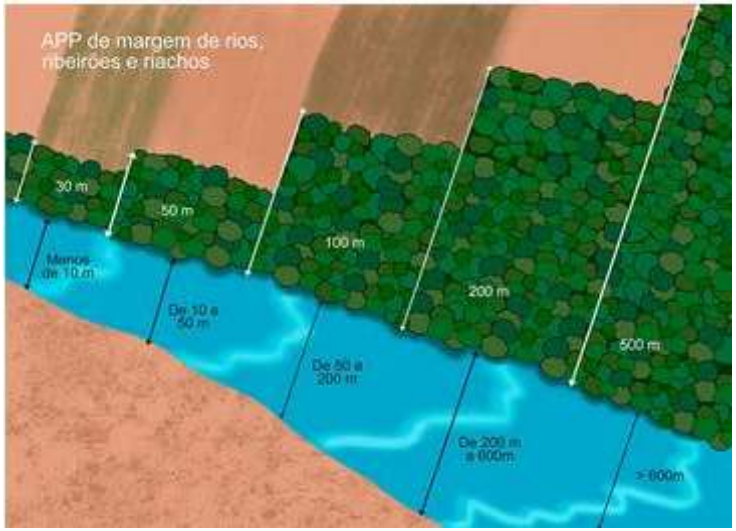

Largura da APP	RIOS (largura
30m	Com menos de 10m
50m	De 10m a 50m
100m	De 50m a 200
200m	De 200m a 600m
500m	Com mais de 600m

Consideram-se Áreas de Preservação Permanente em zonas rurais ou urbanas, as faixas marginais dos dois lados de qualquer curso d'água natural perene ou intermitente.

Várzeas:

Como o novo código estabeleceu o critério de medida da largura do rio a partir da borda da calha de seu leito regular e não mais a partir da máxima cheia as várzeas ou pelo menos parte delas não são mais consideradas Áreas de Preservação Permanente.

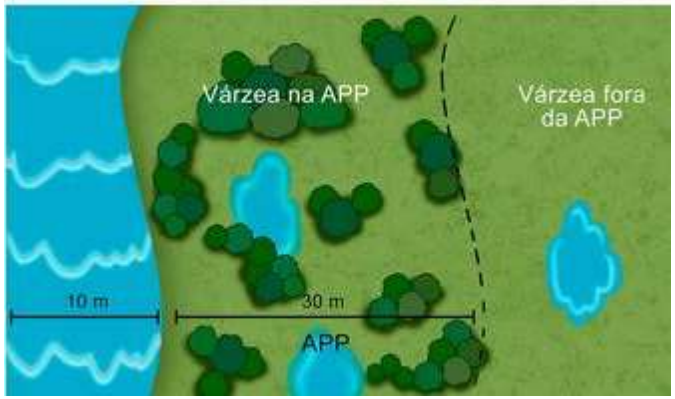

Nascentes:

Para efeito da aplicação da legislação pertinente, é considerado:

- **Nascente:** Afloramento natural do lençol freático que apresenta perenidade e dá início a um curso d'água;
- **Olho d'água:** Afloramento natural do lençol freático mesmo que intermitente.

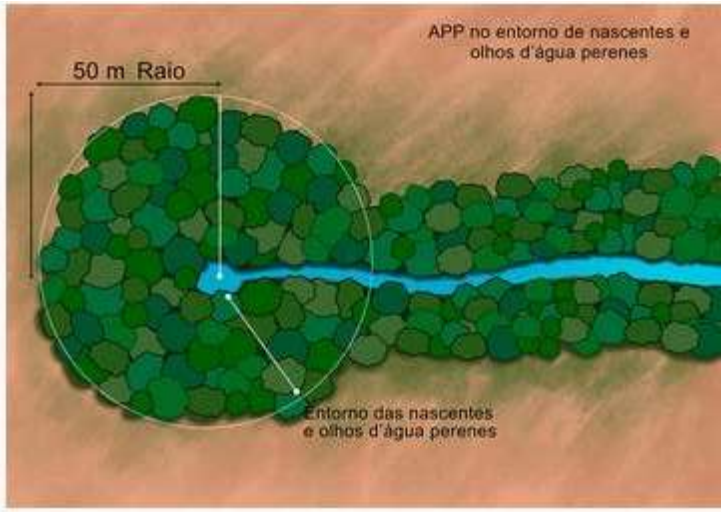

O entorno da nascente ou de um olho d'água perene considerado de preservação permanente deve possuir um raio mínimo de 50 metros

Lagos e nas Lagoas Naturais

São consideradas Áreas de Preservação Permanente o entorno de lagos e lagoas naturais, localizados na zona rural, com largura mínima de:

- 50 metros para corpos d'água com superfície inferior a 20ha;
- 100 metros para corpos d'água com superfície superior a 20ha.

São consideradas Áreas de Preservação Permanente, o entorno de lagos e lagoas naturais, localizados em zona urbana, com largura mínima de 30 metros, independente do tamanho da superfície.

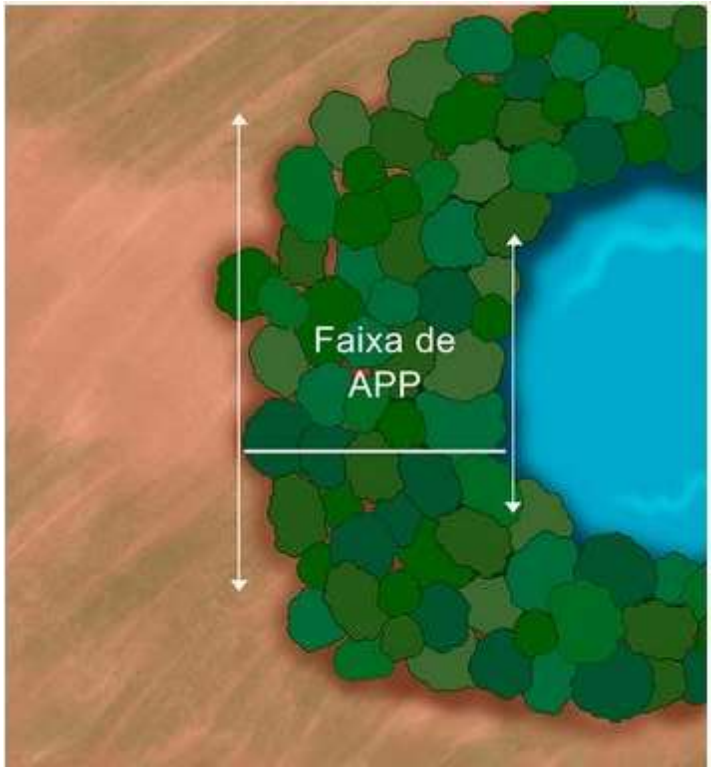

No caso de lagos ou lagoas naturais com superfície inferior a 1,0 ha, a Área de Preservação Permanente é dispensada, no entanto é vedada a supressão da vegetação nativa existente.

Reservatórios Artificiais

Não será exigida Área de Preservação Permanente no entorno de reservatórios artificiais que não decorram de barramento ou represamento de cursos d'água naturais.

No caso dos reservatórios artificiais,decorrentes de barramento ou represamento de cursos d'água naturais, a faixa a ser considerada como Área de Preservação Permanente deverá ser definida na licença ambiental do empreendimento.

Topo de morros montes montanhas e serras

O terço superior do morro é considerado Área de Preservação Permanente.

Para fins de existência de APP, para que uma elevação seja considerado "morro" é preciso que tenha:

a. Altura mínima de 100 metros. Ou seja é preciso que a distância entre o cume e o ponto de sela mais próximo (para terrenos ondulados) ou que a distância entre o cume e a base da planície regular ou curso d´água adjacente (terrenos planos) seja igual ou superior a 100m.

b. Inclinação média mínima de 25º

Não é permitido intervenção em Áreas de APP sem autorização do Órgão Ambiental!

O que deve ser recomposto nas Áreas Rurais Consolidadas?

Ao longo dos cursos d’água naturais

- Para imóveis rurais com área de até 1 (um) módulo fiscal, será obrigatória a recomposição das faixas marginais em 5 (cinco) metros, contados da borda da calha do leito regular, independentemente da largura do curso d’água.
- Para imóveis rurais com área superior a 1 (um) módulo fiscal e de até 2 (dois) módulos fiscais, será obrigatória a recomposição das respectivas faixas marginais em 8 (oito) metros, contados da borda da calha do leito regular, independentemente da largura do curso d'água.
- Para imóveis rurais com área superior a 2 (dois) módulos fiscais e de até 4 (quatro) módulos fiscais, será obrigatória a recomposição das respectivas faixas marginais em 15 (quinze) metros, contados da borda da calha do leito regular, independentemente da largura do curso d'água.
- Para imóveis rurais com área superior a 4 (quatro) módulos fiscais, será obrigatória a recomposição das respectivas faixas marginais, conforme determinação do PRA (Programa de Regularização Ambiental), observado o mínimo de 20 (vinte) e o máximo de 100 (cem) metros, contados da borda da calha do leito regular.

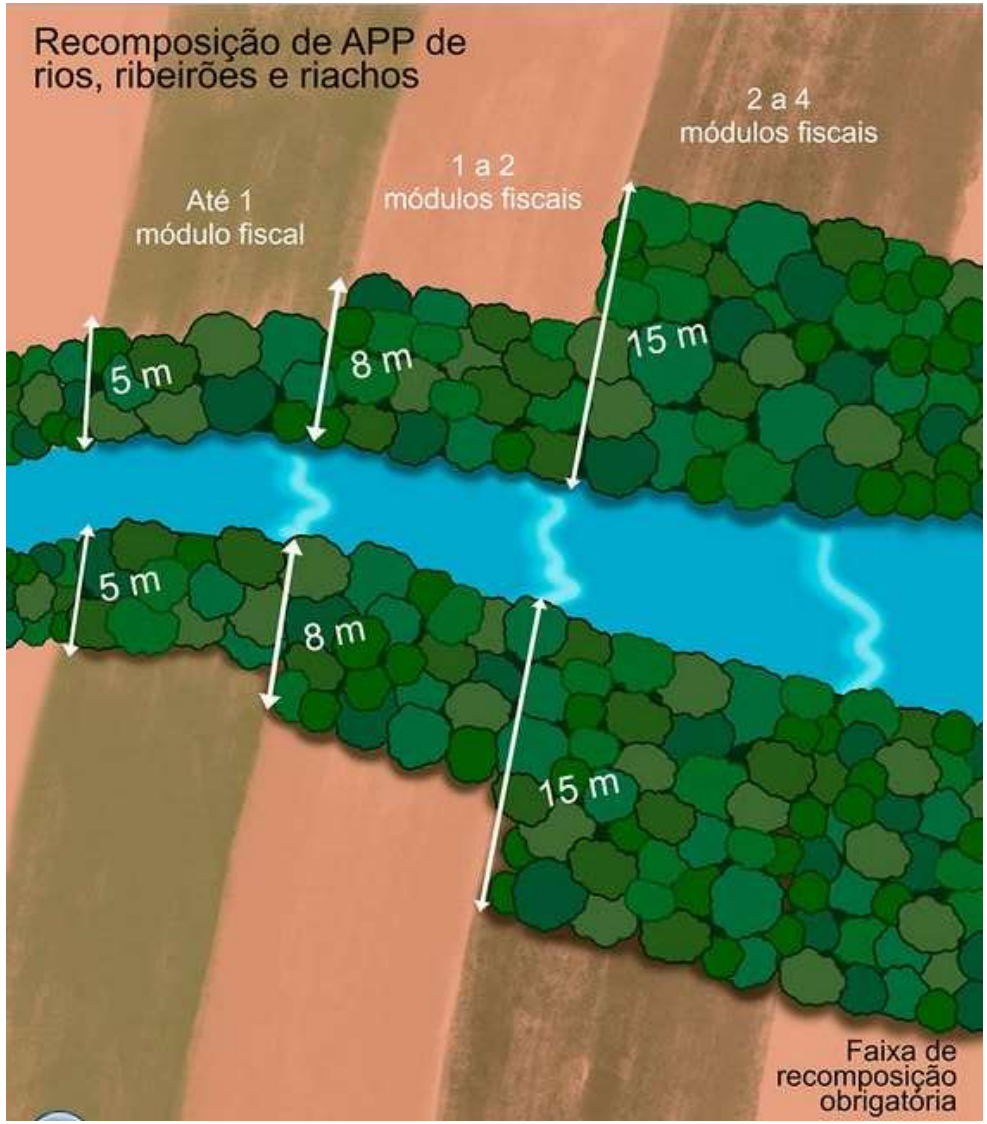

No entorno de nascentes e olhos d'água perenes

- Para qualquer imóvel rural, será obrigatória a recomposição de área com raio mínimo de 15 metros

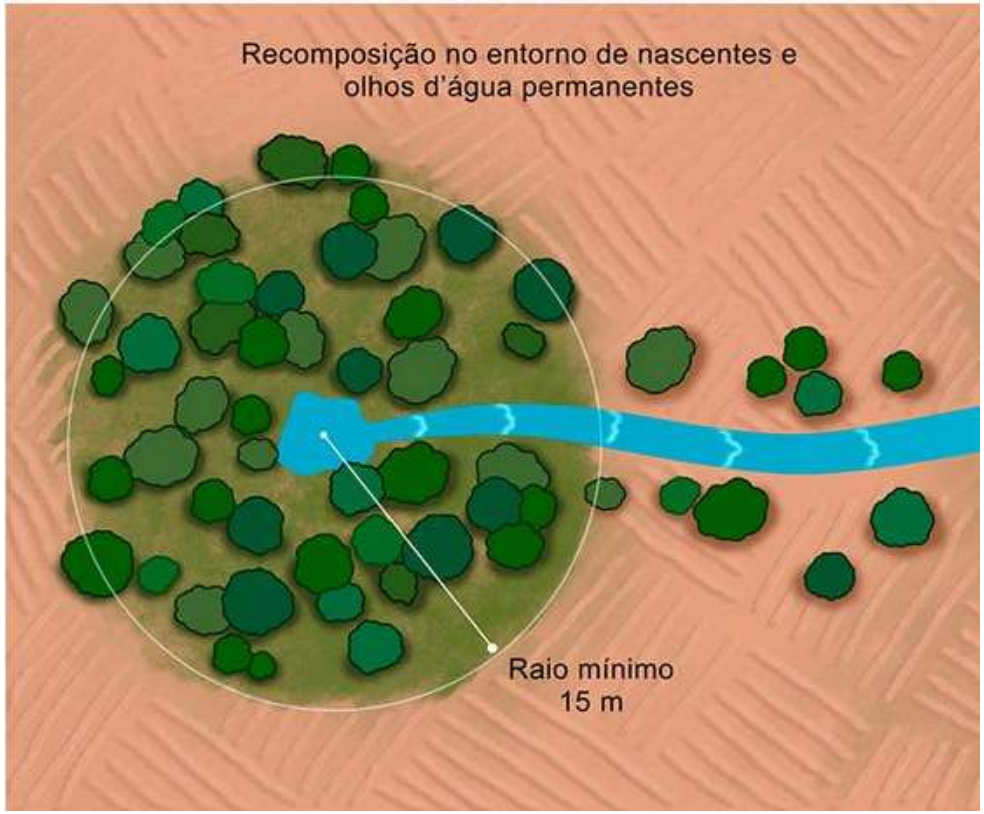

No entorno de lagos e lagoas naturais

- Para imóveis rurais com área de até 1 (um) módulo fiscal, será obrigatória a recomposição de faixa marginal com largura mínima de 5 (cinco) metros.

- Para imóveis rurais com área superior a 1 (um) módulo fiscal e de até 2 (dois) módulos fiscais, será obrigatória a recomposição de faixa marginal com largura mínima de 8 (oito) metros.

- Para imóveis rurais com área superior a 2 (dois) módulos fiscais e de até 4 (quatro) módulos fiscais, será obrigatória a recomposição de faixa marginal com largura mínima de 15 (quinze) metros.

- Para imóveis rurais com área superior a 4 (quatro) módulos fiscais, será obrigatória a recomposição de faixa marginal com largura mínima de 30 (trinta) metros.

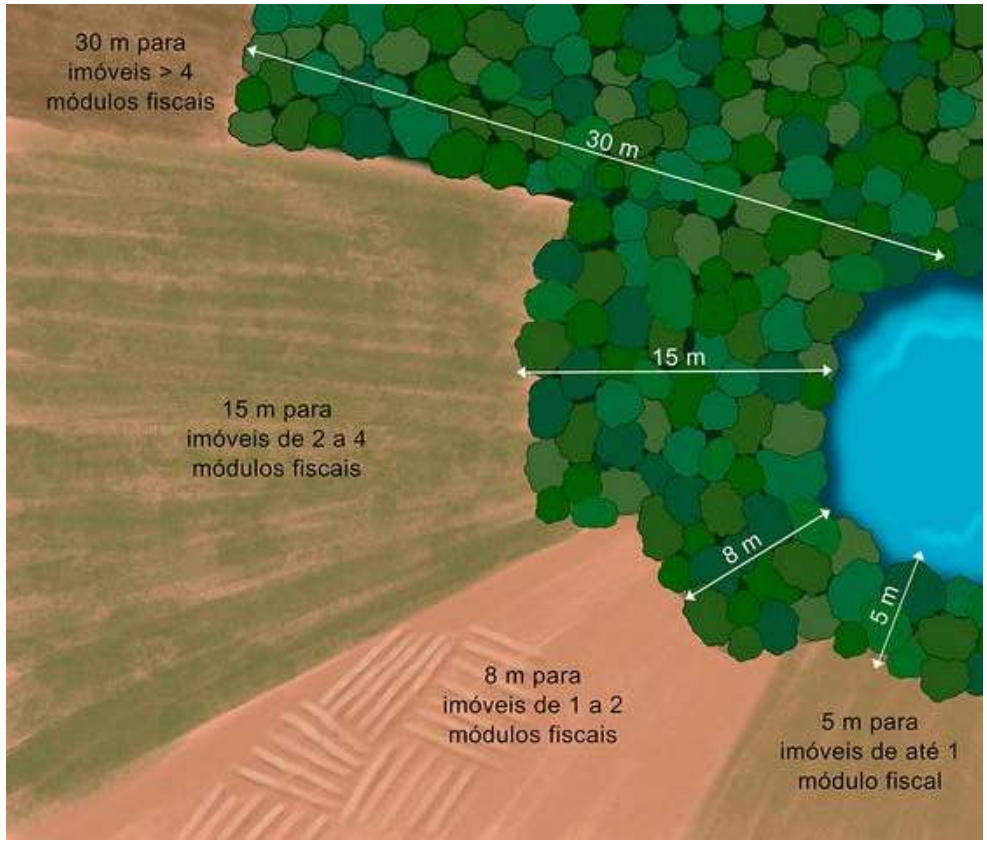

N: 7710802.523
E: 340473.1191
LAT: −20°41'45.0860" (−20.69585722)
LONG: −46°31'55.6452" (−46.53212366)

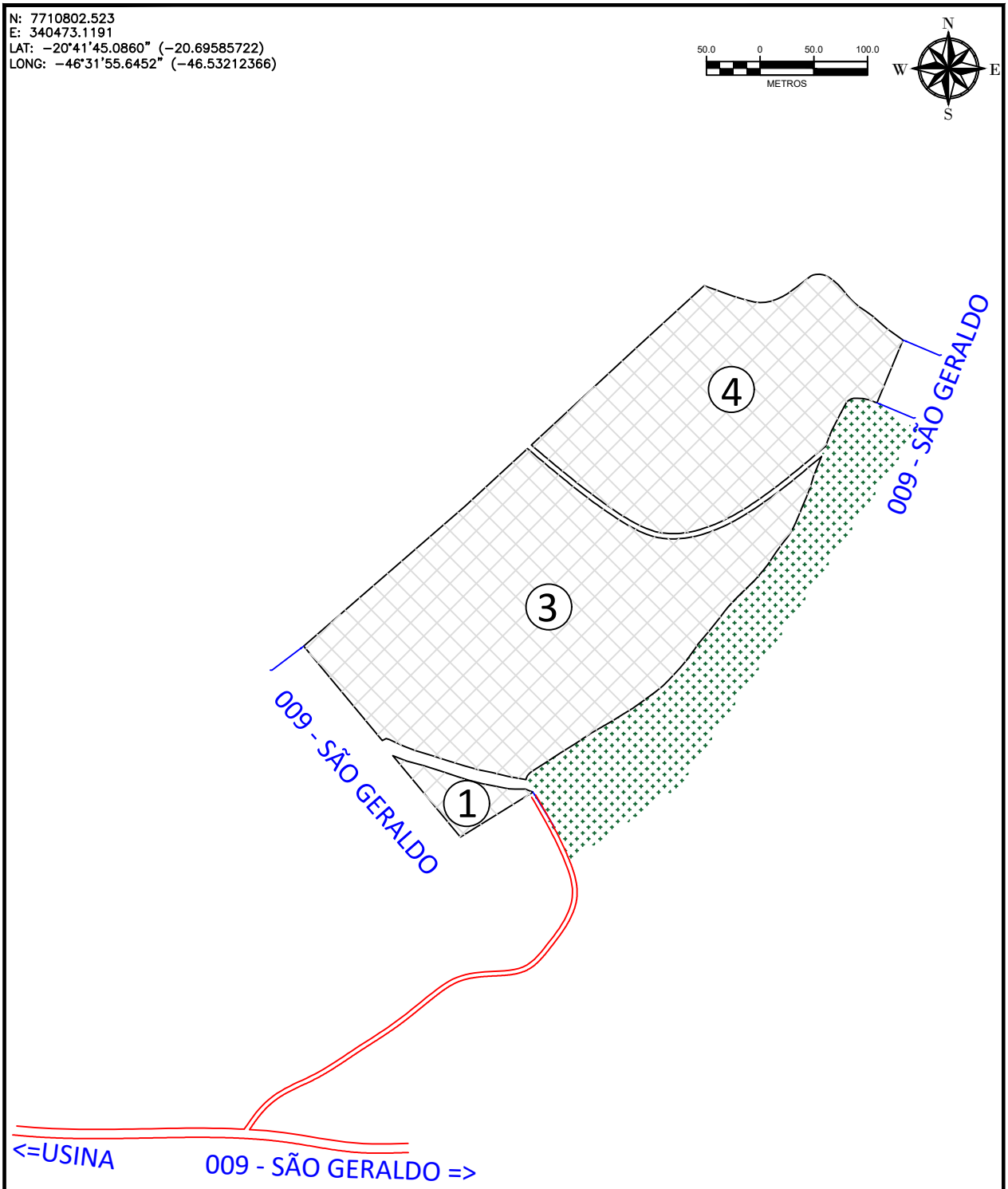

CTC - 4

TABELA DE VARIEDADE

VARIEDADE	ÁREA
CTC4	17,16
Total Geral	**17,16**

IPIRANGA AGROINDUSTRIAL

PROJETO: CADERNO DE MAPA 26,27	DATA: 23/12/2025	ESCALA: 1:5000	TOPÓGRAFO: LUIS DUARTE
FAZENDA: 001 - ALGODÃO	MUNICÍPIO: PASSOS MG		ÁREA (ha): 17,16
PROPRIETÁRIO: ITAIQUARA ALIMENTOS S.A	UNIDADE: IPIRANGA PASSOS		CÓDIGO: 001

Caderno de Mapas

Bloco	Talhao	Variedade	Estágio de Corte	Amb. Prod.	Data Plantio	Último Corte	Área (ha)	Estimativas Área (ha)	Finalid	Produt.	Prod. Total	Dist.	Esp.	Tipo Corte	Experimento
1 · REG 1			**1 · ALGODAO**					**IPIRANGA AGROINDUSTRIAL S.A**							
1	1	CTC4	5C	A	15/11/21	12/09/25	0,48	0,48	1-MO.	82,0	39,36	6	1,5	MEC.	
1	3	CTC4	5C	A	14/11/21	12/09/25	10,16	10,16	1-MO.	82,0	833,12	6	1,5	MEC.	
1	4	CTC4	5C	A	11/11/21	12/09/25	6,52	6,52	1-MO.	82,0	534,64	6	1,5	MEC.	
Total/Média (1 / 1 · ALGODAO)							17,16	17,16		82,0	1.407,12				

N: 7708979.482
E: 347783.4128
LAT: −20°42'46.5647" (−20.71293464)
LONG: −46°27'43.5863" (−46.46210731)

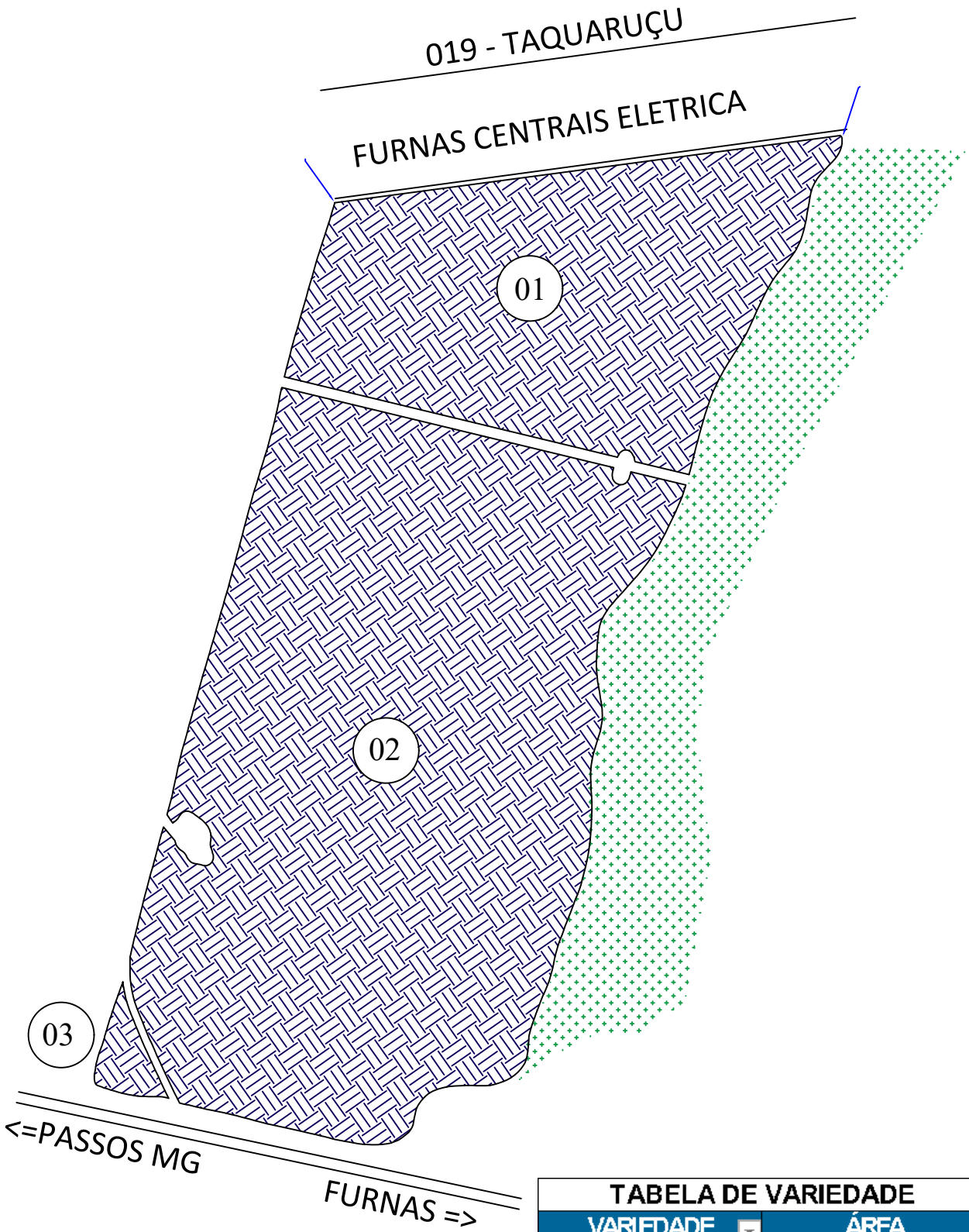

TABELA DE VARIEDADE	
VARIEDADE	ÁREA
CTC9006	33,26
Total Geral	**33,26**

CTC - 9006

IPIRANGA AGROINDUSTRIAL

PROJETO	DATA	ESCALA	TOPÓGRAFO
CADERNO DE MAPA 26'27	01/04/2026	1:5000	CRISTIAN
FAZENDA	**MUNICÍPIO**		**ÁREA (ha)**
002 - CACHOEIRA DO TAQUARUÇU	PASSOS - MG		33,26
PROPRIETÁRIO	**UNIDADE**		**CÓDIGO**
AGROPRCUARIA VALE DO RIO GRANDE	IPIRANGA PASSOS - MG		002

Caderno de Mapas

Bloco	Talhao	Variedade	Estágio de Corte	Amb. Prod.	Data Plantio	Data Último Corte	Área (ha)	Estimativas Área (ha)	Estimativas Finalid	Estimativas Produt.	Prod. Total	Dist.	Esp.	Tipo Corte	Experimento
1 · REG 1			**2 · CACH.TAQUARUÇU**					**IPIRANGA AGROINDUSTRIAL S.A**							
1	1	CTC9006	FORM	A	18/03/26		9,84	0,00	.		0,00	14	1,5	N/D	
1	2	CTC9006	FORM	B	09/03/26		23,08	0,00	.		0,00	14	1,5	N/D	
1	3	CTC9006	FORM	B	18/03/26		0,34	0,00	.		0,00	14	1,5	N/D	
Total/Média (1 / 2 · CACH.TAQUARUÇU)							33,26	0,00			0,00				

N: 7713420.325
E: 337173.5415
LAT: −20°40'18.9373" (−20.67192704)
LONG: −46°33'48.7960" (−46.56355445)

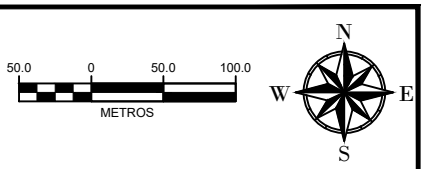

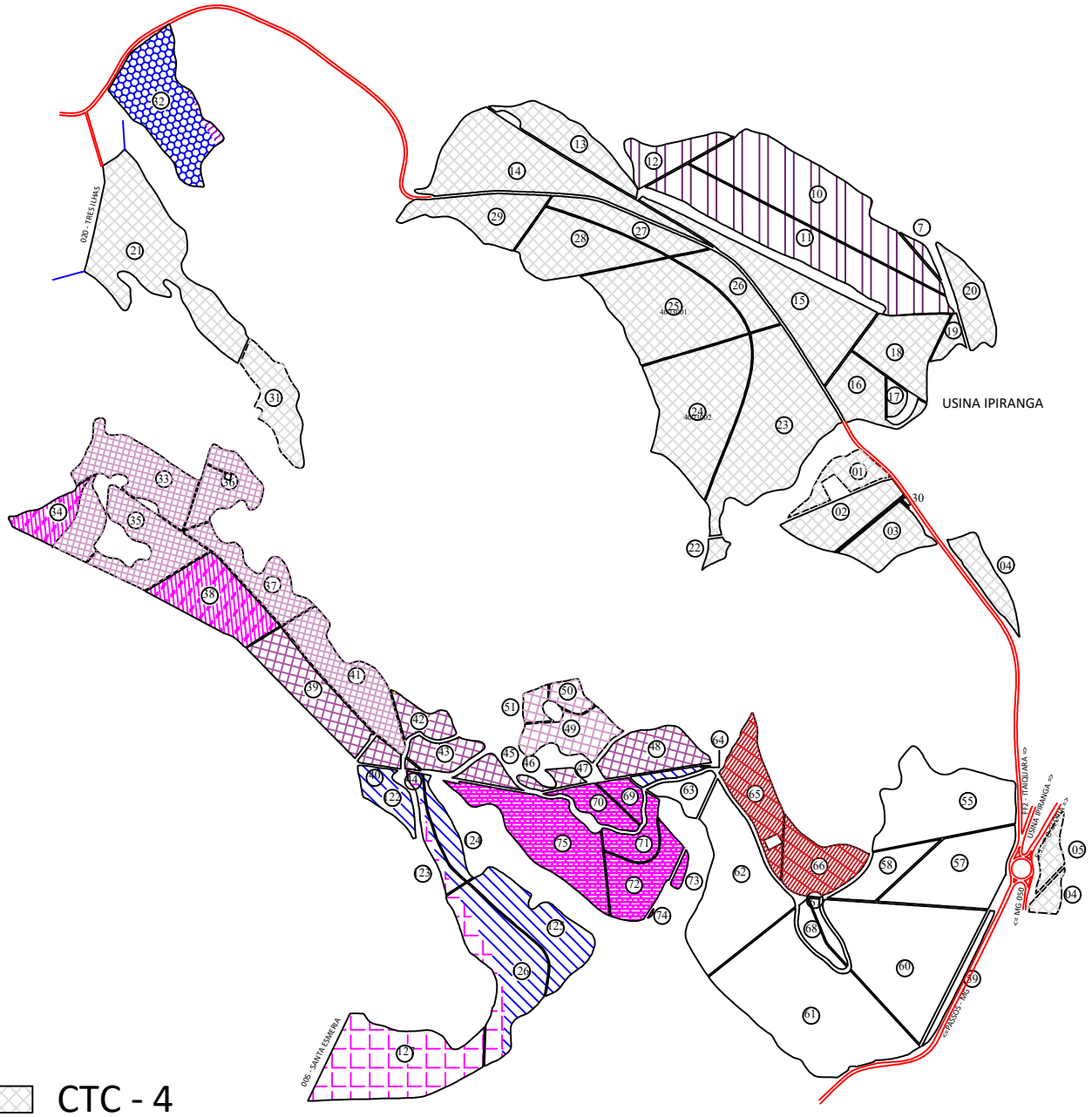

- CTC - 4
- CTC - 9007
- A DEFINIR
- CTC - 2994
- RB 85-5156
- CTC - 3445
- RB 98-7935
- RB 96-6928
- RB 97-5375
- IAC SP 04-6007
- IAC CTC 07-7207
- IAC CTC 07-8008

TABELA DE VARIEDADE

VARIEDADE	ÁREA
A DEFINIR	84,99
CTC2994	10,80
CTC3445	11,28
CTC4	158,51
CTC9007	0,40
IACCTC07-7207	41,22
IACCTC07-8008	20,59
IACSP04-6007	10,76
RB855156	20,47
RB966928	17,77
RB975375	22,71
RB987935	35,23
Total Geral	**434,73**

IPIRANGA AGROINDUSTRIAL

PROJETO	DATA	ESCALA	TOPÓGRAFO
CADERNO DE MAPA 26'27	23-12-2025	1:5000	LUIS DUARTE
FAZENDA	**MUNICÍPIO**		**ÁREA (ha)**
003 - NOVA SOLEDADE	PASSOS MG		434,73
PROPRIETÁRIO	**UNIDADE**		**CÓDIGO**
ITAIQUARA ALIMENTOS S.A	IPIRANGA PASSOS		003

Caderno de Mapas

Bloco	Talhao	Variedade	Estágio de Corte	Amb. Prod.	Data Plantio	Último Corte	Área (ha)	Estimativas Área (ha)	Finalid	Produt.	Prod. Total	Dist.	Esp.	Tipo Corte	Experimento
1 · REG 1			3 · NOVA SOLEDADE				IPIRANGA AGROINDUSTRIAL S.A								
1	1	CTC4	4C	A	07/04/22	15/08/25	3,36	3,36	1-MO.	78,0	262,08	4	1,5	MEC.	
1	2	CTC4	4C	A	07/04/22	15/08/25	5,43	5,43	1-MO.	78,0	423,54	4	1,5	MEC.	
1	3	CTC4	4C	A	06/04/22	15/08/25	4,34	4,34	1-MO.	78,0	338,52	4	1,5	MEC.	
1	4	CTC4	4C	A	07/04/22	15/08/25	3,04	3,04	1-MO.	78,0	237,12	4	1,5	MEC.	
1	5	CTC4	4C	A	10/03/22	29/08/25	0,97	0,97	1-MO.	78,0	75,66	4	1,5	MEC.	
1	6	CTC4	4C	A	10/03/22	29/08/25	1,08	1,08	1-MO.	78,0	84,24	4	1,5	MEC.	
1	7	RB987935	4C	A	24/02/21	17/06/25	0,48	0,48	1-MO.	35,0	16,80	4	1,5	MEC.	
1	10	RB987935	5C	A	24/02/21	17/06/25	16,27	16,27	1-MO.	35,0	569,45	4	1,5	MEC.	
1	11	RB987935	5C	A	24/02/21	17/06/25	14,92	14,92	1-MO.	35,0	522,20	4	1,5	MEC.	
1	12	RB987935	5C	A	25/03/21	17/06/25	3,56	3,56	1-MO.	35,0	124,60	4	1,5	MEC.	
1	13	CTC4	4C	A	05/04/22	15/08/25	5,50	5,50	1-MO.	80,0	440,00	4	1,5	MEC.	
1	14	CTC4	4C	A	05/04/22	15/08/25	14,18	14,18	1-MO.	80,0	1.134,40	4	1,5	MEC.	
1	15	CTC4	4C	A	05/04/22	15/08/25	12,05	12,05	1-MO.	80,0	964,00	4	1,5	MEC.	
1	16	CTC4	4C	A	06/04/22	15/08/25	4,52	4,52	1-MO.	80,0	361,60	4	1,5	MEC.	
1	17	CTC4	4C	A	06/04/22	15/08/25	0,79	0,79	1-MO.	80,0	63,20	4	1,5	MEC.	
1	18	CTC4	4C	A	06/04/22	15/08/25	6,57	6,57	1-MO.	80,0	525,60	4	1,5	MEC.	
1	19	CTC4	4C	A	06/04/22	15/08/25	1,00	1,00	1-MO.	80,0	80,00	4	1,5	MEC.	
1	20	CTC4	4C	A	29/01/22	15/08/25	3,90	3,90	1-MO.	80,0	312,00	4	1,5	MEC.	
1	21	CTC4	4C	B	28/01/22	31/07/25	16,81	16,81	1-MO.	75,0	1.260,75	4	1,5	MEC.	
1	22	CTC4	4C	A	05/04/22	15/08/25	0,65	0,65	1-MO.	80,0	52,00	4	1,5	MEC.	
1	23	CTC4	4C	A	05/04/22	15/08/25	17,97	17,97	1-MO.	67,0	1.203,99	4	1,5	MEC.	
1	24	CTC4	4C	A	04/04/22	15/08/25	14,38	14,38	1-MO.	69,0	992,22	4	1,5	MEC.	
1	25	CTC4	4C	A	03/04/22	15/08/25	13,87	13,87	1-MO.	60,0	832,20	4	1,5	MEC.	
1	26	CTC4	4C	A	03/04/22	15/08/25	4,05	4,05	1-MO.	70,0	283,50	4	1,5	MEC.	
1	27	CTC4	4C	A	04/04/22	15/08/25	4,14	4,14	1-MO.	70,0	289,80	4	1,5	MEC.	
1	28	CTC4	4C	A	04/04/22	15/08/25	8,40	8,40	1-MO.	80,0	672,00	4	1,5	MEC.	
1	29	CTC4	4C	A	04/04/22	15/08/25	6,27	6,27	1-MO.	80,0	501,60	4	1,5	MEC.	
1	30	CTC4	4C	A	07/04/22	15/08/25	0,04	0,04	1-MO.	75,0	3,00	4	1,5	MEC.	
1	31	CTC4	4C	B	04/04/22	31/07/25	5,20	5,20	1-MO.	80,0	416,00	4	1,5	MEC.	
1	32	CTC9007	3C	A	01/04/23	31/07/25	0,40	0,40	1-MO.	55,0	22,00	4	1,5	MEC.	
1	32	IACSP04-6007	3C	A	01/04/23	31/07/25	10,76	10,76	1-MO.	55,0	591,80	4	1,5	MEC.	
1	33	IACCTC07-7207	3C	A	28/02/23	12/08/25	7,72	7,72	1-MO.	75,0	579,00	4	1,5	MEC.	
1	34	CTC2994	3C	CB	22/03/23	12/08/25	2,91	2,91	1-MO.	75,0	218,25	4	1,5	MEC.	
1	34	IACCTC07-7207	3C	CB	22/03/23	12/08/25	2,85	2,85	1-MO.	75,0	213,75	4	1,5	MEC.	
1	35	IACCTC07-7207	3C	CB	22/03/23	12/08/25	6,85	6,85	1-MO.	75,0	513,75	4	1,5	MEC.	
1	36	IACCTC07-7207	4C	A	25/02/23	31/01/25	4,57	4,57	1-MO.	80,0	365,60	4	1,5	MEC.	
1	37	IACCTC07-7207	4C	B	26/02/23	31/01/25	4,89	4,89	1-MO.	80,0	391,20	4	1,5	MEC.	
1	38	CTC2994	3C	B	20/03/23	19/02/25	7,89	7,89	1-MO.	90,0	710,10	4	1,5	MEC.	
1	39	IACCTC07-8008	4C	B	01/06/22	14/11/25	6,85	6,85	1-MO.	60,0	411,00	4	1,5	MEC.	

Caderno de Mapas

Bloco	Talhao	Variedade	Estágio de Corte	Amb. Prod.	Data Plantio	Data Último Corte	Área (ha)	Estimativas Área (ha)	Estimativas Finalid	Estimativas Produt.	Prod. Total	Dist.	Esp.	Tipo Corte	Experimento
1	40	IACCTC07-8008	4C	B	07/07/22	14/11/25	1,13	1,13	1-MO.	60,0	67,80	4	1,5	MEC.	
1	41	IACCTC07-7207	3C	B	26/02/23	31/07/25	7,52	7,52	1-MO.	75,0	564,00	4	1,5	MEC.	
1	42	IACCTC07-8008	4C	B	11/06/22	14/11/25	2,20	2,20	1-MO.	55,0	121,00	4	1,5	MEC.	
1	43	IACCTC07-8008	4C	B	08/06/22	14/11/25	2,59	2,59	1-MO.	55,0	142,45	4	1,5	MEC.	
1	44	IACCTC07-8008	4C	B	09/06/22	14/11/25	0,11	0,11	1-MO.	55,0	6,05	4	1,5	MEC.	
1	45	IACCTC07-8008	4C	A	08/06/22	14/11/25	1,53	1,53	1-MO.	55,0	84,15	4	1,5	MEC.	
1	46	IACCTC07-8008	4C	A	09/06/22	14/11/25	0,36	0,36	1-MO.	55,0	19,80	4	1,5	MEC.	
1	47	IACCTC07-8008	4C	A	09/06/22	14/11/25	0,67	0,67	1-MO.	55,0	36,85	4	1,5	MEC.	
1	48	IACCTC07-8008	4C	A	10/06/22	14/11/25	5,15	5,15	1-MO.	55,0	283,25	4	1,5	MEC.	
1	49	IACCTC07-7207	3C	A	23/03/23	31/07/25	4,37	4,37	1-MO.	76,0	332,12	4	1,5	MEC.	
1	50	IACCTC07-7207	3C	A	23/03/23	13/01/25	1,39	1,39	1-MO.	76,0	105,64	4	1,5	MEC.	
1	51	IACCTC07-7207	3C	A	23/03/23	13/01/25	1,06	1,06	1-MO.	76,0	80,56	4	1,5	MEC.	
1	55	A DEFINIR	REFORM	A	01/01/26		12,01	0,00	.		0,00	4	1,5	N/D	
1	57	A DEFINIR	REFORM	A	01/01/26		9,38	0,00	.		0,00	4	1,5	N/D	
1	58	A DEFINIR	REFORM	A	01/01/26		3,39	0,00	.		0,00	4	1,5	N/D	
1	59	A DEFINIR	REFORM	A	01/01/26		1,22	0,00	.		0,00	4	1,5	N/D	
1	60	A DEFINIR	REFORM	A	01/01/26		17,36	0,00	.		0,00	4	1,5	N/D	
1	61	A DEFINIR	REFORM	A	01/01/26		22,51	0,00	.		0,00	4	1,5	N/D	
1	62	A DEFINIR	REFORM	A	01/01/26		14,07	0,00	.		0,00	4	1,5	N/D	
1	63	A DEFINIR	REFORM	A	01/01/26		2,06	0,00	.		0,00	4	1,5	N/D	
1	64	A DEFINIR	REFORM	A	01/01/26		0,76	0,00	.		0,00	4	1,5	N/D	
1	65	CTC3445	FORM	B	30/03/26		5,82	0,00	.		0,00	4	1,5	N/D	
1	66	CTC3445	FORM	A	31/03/26		5,46	0,00	.		0,00	4	1,5	N/D	
1	67	A DEFINIR	REFORM	A	01/01/26		0,78	0,00	.		0,00	4	1,5	N/D	
1	68	A DEFINIR	REFORM	A	01/01/26		1,45	0,00	.		0,00	4	1,5	N/D	
1	69	RB975375	1C	A	22/03/25	22/01/26	1,43	0,37	2-MU.	60,0	22,20	4	1,5	MEC.	
1	69	RB975375	1C	A	22/03/25	22/01/26	1,43	1,06	1-MO.	100,0	106,00	4	1,5	MEC.	
1	70	RB975375	1C	A	22/03/25	22/01/26	2,37	0,54	2-MU.	60,0	32,40	4	1,5	MEC.	
1	70	RB975375	1C	A	22/03/25	22/01/26	2,37	1,83	1-MO.	100,0	183,00	4	1,5	MEC.	
1	71	RB975375	1C	A	22/03/25		2,54	2,54	1-MO.	132,0	335,28	4	1,5	MEC.	
1	72	RB975375	1C	A	22/03/25		5,26	5,26	1-MO.	132,0	694,32	4	1,5	MEC.	
1	73	RB975375	1C	A	22/03/25	22/01/26	0,41	0,41	2-MU.	50,0	20,50	4	1,5	MEC.	
1	74	RB975375	1C	A	22/03/25	22/01/26	0,02	0,02	2-MU.	50,0	1,00	4	1,5	MEC.	
1	75	RB975375	1C	A	22/03/25		10,68	10,68	1-MO.	110,0	1.174,80	4	1,5	MEC.	
1	122	RB855156	4C	B	28/03/22	05/06/25	2,78	2,78	1-MO.	57,0	158,46	4	1,5	MEC.	
1	123	RB855156	4C	B	22/03/22	05/06/25	0,95	0,95	1-MO.	57,0	54,15	4	1,5	MEC.	
1	123	RB966928	4C	B	22/03/22	05/06/25	0,98	0,98	1-MO.	57,0	55,86	4	1,5	MEC.	
1	124	RB855156	4C	A	22/03/22	05/06/25	2,16	2,16	1-MO.	57,0	123,12	4	1,5	MEC.	
1	125	RB855156	4C	A	22/03/22	05/06/25	7,22	7,22	1-MO.	57,0	411,54	4	1,5	MEC.	
1	126	RB855156	4C	A	22/03/22	05/06/25	7,36	7,36	1-MO.	57,0	419,52	4	1,5	MEC.	
1	126	RB966928	4C	A	22/03/22	05/06/25	3,28	3,28	1-MO.	57,0	186,96	4	1,5	MEC.	

N: 7713420.325
E: 337173.5415
LAT: −20°40'18.9373" (−20.67192704)
LONG: −46°33'48.7960" (−46.56355445)

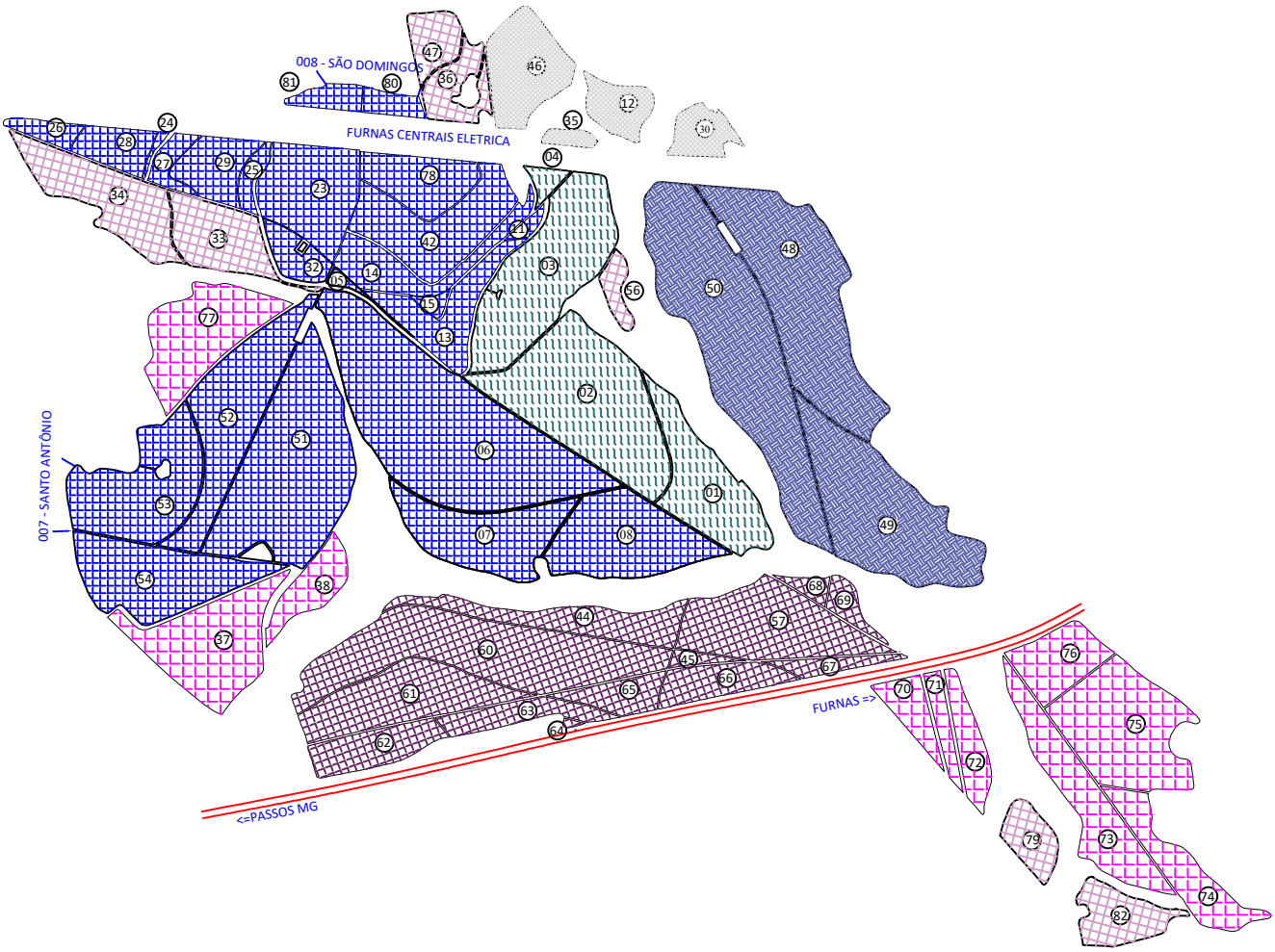

CTC - 2
CTC - 4
CTC - 9009
CTC - 9003
RB 97-5952
RB 96-6928
IAC CTC 07-7207

TABELA DE VARIEDADE

VARIEDADE	ÁREA
CTC2	117,24
CTC4	10,31
CTC9003	46,35
CTC9009	32,96
IACCTC07-7207	22,57
RB966928	48,33
RB975952	48,60
Total Geral	**326,36**

IPIRANGA AGROINDUSTRIAL

PROJETO	DATA	ESCALA	TOPÓGRAFO
CADERNO DE MAPA 26'27	25/05/2026	1:5000	CRISTIAN
FAZENDA	**MUNICÍPIO**		**ÁREA (ha)**
004 - POÇO	PASSOS MG		356,36
PROPRIETÁRIO	**UNIDADE**		**CÓDIGO**
ITAIQUARA ALIMENTOS S.A	IPIRANGA PASSOS		004

Caderno de Mapas

Bloco	Talhao	Variedade	Estágio de Corte	Amb. Prod.	Data Plantio	Último Corte	Área (ha)	Estimativas Área (ha)	Finalid	Produt.	Prod. Total	Dist.	Esp.	Tipo Corte	Experimento
1 · REG 1			**4 · POÇO**				**IPIRANGA AGROINDUSTRIAL S.A**								
1	1	CTC9009	1C	A	19/02/25	14/04/26	6,96	6,96	1-MO.	125,0	870,00	11	1,5	MEC.	
1	2	CTC9009	1C	A	18/02/25	14/04/26	14,09	14,09	1-MO.	125,0	1.761,25	11	1,5	MEC.	
1	3	CTC9009	1C	A	17/02/25	14/04/26	11,26	11,26	1-MO.	125,0	1.407,50	11	1,5	MEC.	
1	4	CTC9009	1C	A	18/02/25	14/04/26	0,65	0,65	1-MO.	125,0	81,25	11	1,5	MEC.	
1	5	CTC2	FORM	A	30/04/26		0,33	0,00	.		0,00	11	1,5	N/D	
1	6	CTC2	FORM	A	30/04/26		22,36	0,00	.		0,00	11	1,5	N/D	
1	7	CTC2	FORM	A	29/04/26		7,06	0,00	.		0,00	11	1,5	N/D	
1	8	CTC2	FORM	A	29/04/26		8,08	0,00	.		0,00	11	1,5	N/D	
1	11	CTC2	6C	A	15/02/20	13/11/25	0,37	0,37	1-MO.	65,0	24,05	11	1,5	MEC.	
1	12	CTC4	3C	BA	30/04/23	10/10/25	2,27	2,27	1-MO.	77,0	174,79	11	1,5	MEC.	
1	13	CTC2	6C	A	15/02/20	13/11/25	4,21	4,21	1-MO.	65,0	273,65	11	1,5	MEC.	
1	14	CTC2	6C	A	15/02/20	13/11/25	3,71	3,71	1-MO.	68,0	252,28	11	1,5	MEC.	
1	15	CTC2	6C	A	15/02/20	13/11/25	0,38	0,38	1-MO.	68,0	25,84	11	1,5	MEC.	
1	23	CTC2	7C	A	16/05/19	13/11/25	6,62	6,62	1-MO.	68,0	450,16	11	1,5	MEC.	
1	24	CTC2	7C	A	30/03/19	13/11/25	0,16	0,16	1-MO.	68,0	10,88	11	1,5	MEC.	
1	25	CTC2	7C	A	30/03/19	13/11/25	0,82	0,82	1-MO.	68,0	55,76	11	1,5	MEC.	
1	26	CTC2	7C	A	30/03/19	13/11/25	1,04	1,04	1-MO.	68,0	70,72	11	1,5	MEC.	
1	27	CTC2	7C	A	30/03/19	13/11/25	1,08	1,08	1-MO.	68,0	73,44	11	1,5	MEC.	
1	28	CTC2	7C	A	30/03/19	13/11/25	2,17	2,17	1-MO.	68,0	147,56	11	1,5	MEC.	
1	29	CTC2	7C	A	30/03/19	13/11/25	2,96	2,96	1-MO.	68,0	201,28	11	1,5	MEC.	
1	30	CTC4	3C	BA	30/04/23	10/10/25	2,02	2,02	1-MO.	80,0	161,60	11	1,5	MEC.	
1	32	CTC2	2C	A	04/12/23	17/04/26	1,74	1,74	1-MO.	100,0	174,00	11	1,5	MEC.	
1	33	IACCTC07-7207	2C	A	01/02/24	14/04/26	4,68	4,68	1-MO.	100,0	468,00	11	1,5	MEC.	
1	34	IACCTC07-7207	2C	A	02/02/24	14/04/26	6,59	6,59	1-MO.	100,0	659,00	11	1,5	MEC.	
1	35	CTC4	3C	BA	30/04/23	10/10/25	0,43	0,43	1-MO.	80,0	34,40	11	1,5	MEC.	
1	36	IACCTC07-7207	3C	BA	01/02/24	10/10/25	2,54	2,54	1-MO.	80,0	203,20	11	1,5	MEC.	
1	37	RB966928	4C	BA	21/12/21	14/04/26	8,29	8,29	1-MO.	75,0	621,75	11	1,5	MEC.	
1	38	RB966928	4C	A	27/12/21	14/04/26	2,67	2,67	1-MO.	75,0	200,25	11	1,5	MEC.	
1	42	CTC2	6C	A	15/02/20	13/11/25	7,02	7,02	1-MO.	65,0	456,30	11	1,5	MEC.	
1	44	RB975952	5C	A	06/08/21	24/10/25	4,68	4,68	1-MO.	68,0	318,24	11	1,5	MEC.	
1	45	RB975952	5C	A	06/08/21	24/10/25	0,50	0,50	1-MO.	68,0	34,00	11	1,5	MEC.	
1	46	CTC4	3C	BA	30/04/23	10/10/25	5,59	5,59	1-MO.	75,0	419,25	11	1,5	MEC.	
1	47	IACCTC07-7207	3C	A	01/02/24	10/10/25	2,13	2,13	1-MO.	75,0	159,75	11	1,5	MEC.	
1	48	CTC9003	2C	BA	15/11/23	31/03/26	14,80	14,80	1-MO.	105,0	1.554,00	11	1,5	MEC.	
1	49	CTC9003	2C	BA	16/11/23	31/03/26	12,70	12,70	1-MO.	105,0	1.333,50	11	1,5	MEC.	
1	50	CTC9003	2C	BA	15/11/23	31/03/26	18,85	18,85	1-MO.	105,0	1.979,25	11	1,5	MEC.	
1	51	CTC2	2C	BA	17/11/23	17/04/26	15,29	15,29	1-MO.	100,0	1.529,00	11	1,5	MEC.	
1	52	CTC2	2C	BA	18/11/23	17/04/26	8,96	8,96	1-MO.	100,0	896,00	11	1,5	MEC.	
1	53	CTC2	2C	A	17/11/23	17/04/26	8,58	8,58	1-MO.	100,0	858,00	11	1,5	MEC.	

Caderno de Mapas

Bloco	Talhao	Variedade	Estágio de Corte	Amb. Prod.	Data Plantio	Data Último Corte	Área (ha)	Estimativas Área (ha)	Estimativas Finalid	Estimativas Produt.	Prod. Total	Dist.	Esp.	Tipo Corte	Experimento
1	54	CTC2	2C	BA	17/11/23	17/04/26	8,05	8,05	1-MO.	100,0	805,00	11	1,5	MEC.	
1	56	IACCTC07-7207	2C	A	01/02/24	14/04/26	1,08	1,08	1-MO.	100,0	108,00	11	1,5	MEC.	
1	57	RB975952	5C	A	06/08/21	24/10/25	8,38	8,38	1-MO.	65,0	544,70	11	1,5	MEC.	
1	60	RB975952	5C	C	06/08/21	24/10/25	14,14	14,14	1-MO.	65,0	919,10	11	1,5	MEC.	
1	61	RB975952	5C	C	19/02/21	23/10/25	7,21	7,21	1-MO.	65,0	468,65	11	1,5	MEC.	
1	62	RB975952	6C	C	19/02/21	23/10/25	3,38	3,38	1-MO.	65,0	219,70	11	1,5	MEC.	
1	63	RB975952	5C	C	19/02/21	23/10/25	2,46	2,46	1-MO.	65,0	159,90	11	1,5	MEC.	
1	64	RB975952	5C	C	06/08/21	24/10/25	0,09	0,09	1-MO.	65,0	5,85	11	1,5	MEC.	
1	65	RB975952	5C	C	06/08/21	24/10/25	2,05	2,05	1-MO.	65,0	133,25	11	1,5	MEC.	
1	66	RB975952	5C	C	06/08/21	24/10/25	2,88	2,88	1-MO.	65,0	187,20	11	1,5	MEC.	
1	67	RB975952	5C	A	06/08/21	24/10/25	1,15	1,15	1-MO.	65,0	74,75	11	1,5	MEC.	
1	68	RB975952	4C	A	29/12/21	24/10/25	0,61	0,61	1-MO.	65,0	39,65	11	1,5	MEC.	
1	69	RB975952	5C	A	27/12/21	24/10/25	1,07	1,07	1-MO.	65,0	69,55	11	1,5	MEC.	
1	70	RB966928	4C	A	27/12/21	27/03/26	1,97	1,97	1-MO.	75,0	147,75	11	1,5	MEC.	
1	71	RB966928	4C	A	27/12/21	27/03/26	1,20	1,20	1-MO.	75,0	90,00	11	1,5	MEC.	
1	72	RB966928	4C	A	27/12/21	27/03/26	2,34	2,34	1-MO.	75,0	175,50	11	1,5	MEC.	
1	73	RB966928	4C	D	25/12/21	27/03/26	6,72	6,72	1-MO.	75,0	504,00	11	1,5	MEC.	
1	74	RB966928	4C	D	23/12/21	27/03/26	4,42	4,42	1-MO.	75,0	331,50	11	1,5	MEC.	
1	75	RB966928	4C	B	22/12/21	27/03/26	9,84	9,84	1-MO.	75,0	738,00	11	1,5	MEC.	
1	76	RB966928	4C	B	23/12/21	27/03/26	3,69	3,69	1-MO.	75,0	276,75	11	1,5	MEC.	
1	77	RB966928	4C	BA	17/12/21	14/04/26	7,19	7,19	1-MO.	75,0	539,25	11	1,5	MEC.	
1	78	CTC2	6C	A	15/02/20	13/11/25	4,03	4,03	1-MO.	69,0	278,07	11	1,5	MEC.	
1	79	IACCTC07-7207	2C	A	01/02/24	27/03/26	2,21	2,21	1-MO.	105,0	232,05	11	1,5	MEC.	
1	80	CTC2	6C	A	07/03/20	10/10/25	1,04	1,04	1-MO.	69,0	71,76	11	1,5	MEC.	
1	81	CTC2	6C	A	07/03/20	10/10/25	1,18	1,18	1-MO.	69,0	81,42	11	1,5	MEC.	
1	82	IACCTC07-7207	2C	D	01/02/24	27/03/26	3,34	3,34	1-MO.	100,0	334,00	11	1,5	MEC.	
Total/Média (1 / 4 · POÇO)							326,36	288,53		88,3	25.475,25				

N: 7711888.191
E: 334605.0111
LAT: −20°41'7.9466" (−20.68554072)
LONG: −46°35'18.0596" (−46.58834988)

TABELA DE VARIEDADE

VARIEDADE	ÁREA
CTC2994	10,77
IACCTC07-7207	25,7
IACSP01-5503	61,12
RB005014	15,53
RB855156	23,73
RB855453	5,66
RB867515	17,48
RB966928	75,35
RB985476	40,99
Total Geral	**276,33**

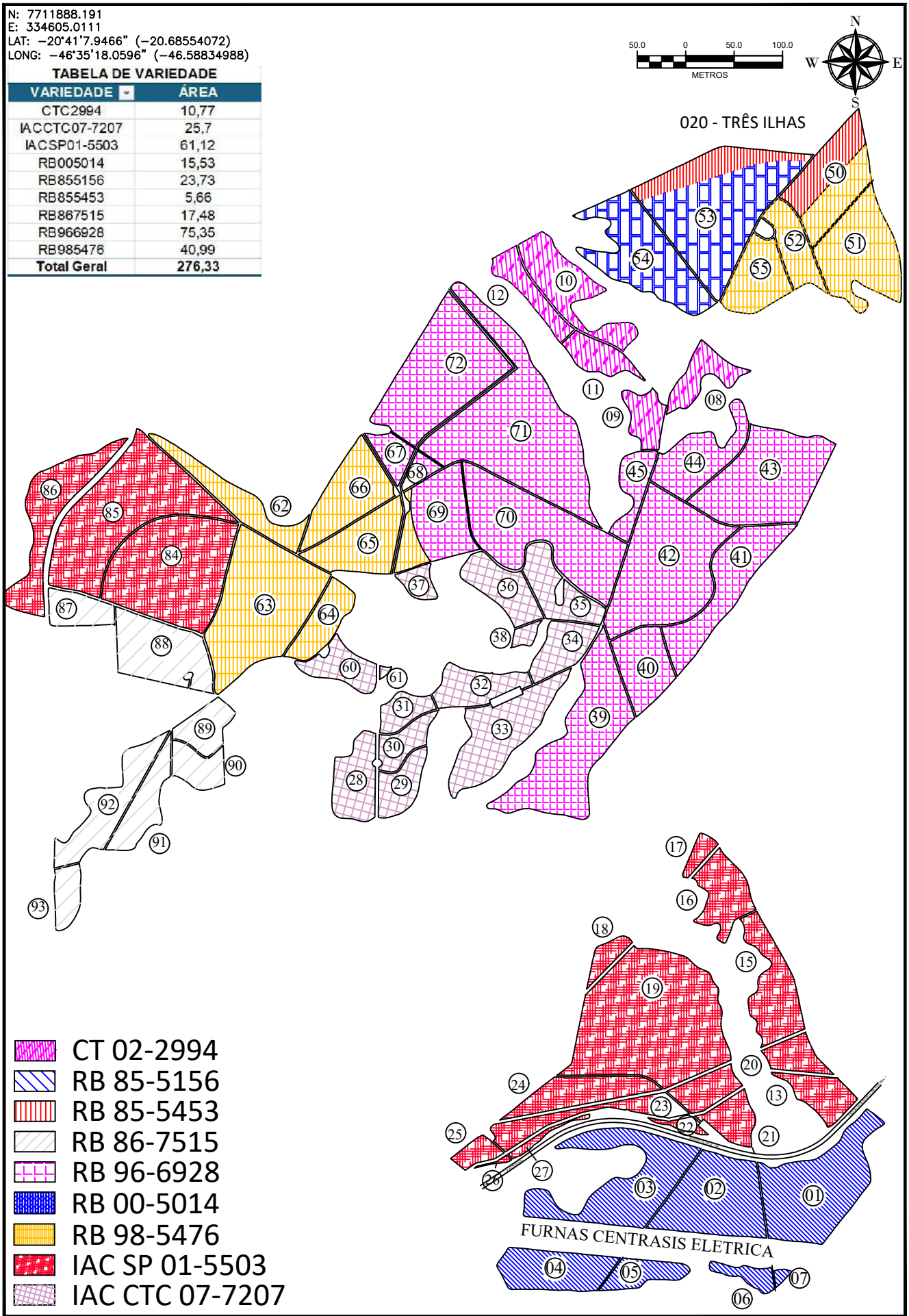

IPIRANGA AGROINDUSTRIAL	PROJETO: CADERNO DE MAPA 26'27	DATA: 23-12-2025	ESCALA: 1:5000	TOPÓGRAFO: CRISTIAN
	FAZENDA: 005 SANTA ESMERIA	MUNICÍPIO: PASSOS MG		ÁREA (ha): 276,33
	PROPRIETÁRIO: ITAIQUARA ALIMENTOS S.A	UNIDADE: IPIRANGA PASSOS		CÓDIGO: 005

Caderno de Mapas

Bloco	Talhao	Variedade	Estágio de Corte	Amb. Prod.	Data Plantio	Data Último Corte	Área (ha)	Estimativas Área (ha)	Estimativas Finalid	Estimativas Produt.	Prod. Total	Dist.	Esp.	Tipo Corte	Experimento
1 · REG 1			5 · STA.ESMERIA				IPIRANGA AGROINDUSTRIAL S.A								
1	1	RB855156	4C	CB	28/02/22	06/04/26	6,10	6,10	1-MO.	55,0	335,50	6	1,5	MEC.	
1	2	RB855156	4C	B	30/03/22	06/04/26	5,34	5,34	1-MO.	55,0	293,70	6	1,5	MEC.	
1	3	RB855156	4C	CB	30/03/22	06/04/26	6,04	6,04	1-MO.	55,0	332,20	6	1,5	MEC.	
1	4	RB855156	4C	C	30/03/22	06/04/26	3,74	3,74	1-MO.	55,0	205,70	6	1,5	MEC.	
1	5	RB855156	4C	B	30/03/22	06/04/26	1,61	1,61	1-MO.	55,0	88,55	6	1,5	MEC.	
1	6	RB855156	4C	CB	30/03/22	06/04/26	0,77	0,77	1-MO.	55,0	42,35	6	1,5	MEC.	
1	7	RB855156	4C	CB	30/03/22	06/04/26	0,13	0,13	1-MO.	55,0	7,15	6	1,5	MEC.	
1	8	CTC2994	3C	CB	28/02/23	13/05/25	1,92	1,92	1-MO.	92,0	176,64	6	1,5	MEC.	
1	9	CTC2994	3C	CB	29/03/23	21/02/25	1,56	1,56	1-MO.	92,0	143,52	6	1,5	MEC.	
1	10	CTC2994	3C	CB	28/02/23	13/05/25	3,88	3,88	1-MO.	92,0	356,96	6	1,5	MEC.	
1	11	CTC2994	3C	CB	28/03/23	21/02/25	1,65	1,65	1-MO.	92,0	151,80	6	1,5	MEC.	
1	12	CTC2994	3C	CB	28/02/23	21/02/25	1,76	1,76	1-MO.	92,0	161,92	6	1,5	MEC.	
1	13	IACSP01-5503	2C	B	23/11/23	23/05/25	1,90	1,90	1-MO.	95,0	180,50	6	1,5	MEC.	
1	14	IACSP01-5503	2C	BA	23/11/23	23/05/25	1,40	1,40	1-MO.	95,0	133,00	6	1,5	MEC.	
1	15	IACSP01-5503	2C	BA	15/12/23	23/05/25	3,73	3,73	1-MO.	95,0	354,35	6	1,5	MEC.	
1	16	IACSP01-5503	2C	BA	07/12/23	23/05/25	2,71	2,71	1-MO.	95,0	257,45	6	1,5	MEC.	
1	17	IACSP01-5503	2C	BA	24/11/23	23/05/25	0,58	0,58	1-MO.	95,0	55,10	6	1,5	MEC.	
1	18	IACSP01-5503	2C	C	17/01/24	23/05/25	0,79	0,79	1-MO.	95,0	75,05	6	1,5	MEC.	
1	19	IACSP01-5503	2C	C	20/12/23	23/05/25	14,52	14,52	1-MO.	95,0	1.379,40	6	1,5	MEC.	
1	20	IACSP01-5503	2C	B	16/01/24	23/05/25	1,61	1,61	1-MO.	95,0	152,95	6	1,5	MEC.	
1	21	IACSP01-5503	2C	B	16/01/24	23/05/25	1,54	1,54	1-MO.	95,0	146,30	6	1,5	MEC.	
1	22	IACSP01-5503	2C	B	17/01/24	23/05/25	0,38	0,38	1-MO.	95,0	36,10	6	1,5	MEC.	
1	23	IACSP01-5503	2C	CB	17/01/24	23/05/25	2,27	2,27	1-MO.	95,0	215,65	6	1,5	MEC.	
1	24	IACSP01-5503	2C	CB	17/01/24	23/05/25	2,89	2,89	1-MO.	95,0	274,55	6	1,5	MEC.	
1	25	IACSP01-5503	2C	CB	17/01/24	23/05/25	0,82	0,82	1-MO.	95,0	77,90	6	1,5	MEC.	
1	26	IACSP01-5503	2C	CB	16/01/24	23/05/25	0,07	0,07	1-MO.	95,0	6,65	6	1,5	MEC.	
1	27	IACSP01-5503	2C	CB	18/01/24	23/05/25	0,33	0,33	1-MO.	95,0	31,35	6	1,5	MEC.	
1	28	IACCTC07-7207	1C	A	15/02/25		2,79	2,79	1-MO.	127,0	354,33	6	1,5	MEC.	
1	29	IACCTC07-7207	1C	A	14/02/25		1,82	1,82	1-MO.	127,0	231,14	6	1,5	MEC.	
1	30	IACCTC07-7207	1C	A	14/02/25		1,47	1,47	1-MO.	127,0	186,69	6	1,5	MEC.	
1	31	IACCTC07-7207	1C	A	14/02/25		1,27	1,27	1-MO.	127,0	161,29	6	1,5	MEC.	
1	32	IACCTC07-7207	1C	A	08/02/25		2,39	2,39	1-MO.	127,0	303,53	6	1,5	MEC.	
1	33	IACCTC07-7207	1C	A	03/02/25		5,19	5,19	1-MO.	127,0	659,13	6	1,5	MEC.	
1	34	IACCTC07-7207	1C	C	30/01/25		2,16	2,16	1-MO.	127,0	274,32	6	1,5	MEC.	
1	35	IACCTC07-7207	1C	C	30/01/25		2,73	2,73	1-MO.	127,0	346,71	6	1,5	MEC.	
1	36	IACCTC07-7207	1C	C	29/01/25		2,62	2,62	1-MO.	127,0	332,74	6	1,5	MEC.	
1	37	IACCTC07-7207	1C	C	14/02/25		0,81	0,81	1-MO.	127,0	102,87	6	1,5	MEC.	
1	38	IACCTC07-7207	1C	C	30/01/25		0,40	0,40	1-MO.	127,0	50,80	6	1,5	MEC.	
1	39	RB966928	4C	A	24/03/22	13/05/25	8,81	8,81	1-MO.	69,0	607,89	6	1,5	MEC.	

Caderno de Mapas

Bloco	Talhao	Variedade	Estágio de Corte	Amb. Prod.	Data Plantio	Data Último Corte	Área (ha)	Estimativas Área (ha)	Estimativas Finalid	Estimativas Produt.	Prod. Total	Dist.	Esp.	Tipo Corte	Experimento
1	40	RB966928	4C	C	26/03/22	13/05/25	3,17	3,17	1-MO.	69,0	218,73	6	1,5	MEC.	
1	41	RB966928	4C	C	25/03/22	13/05/25	5,05	5,05	1-MO.	69,0	348,45	6	1,5	MEC.	
1	42	RB966928	4C	C	24/03/22	13/05/25	10,13	10,13	1-MO.	69,0	698,97	6	1,5	MEC.	
1	43	RB966928	4C	B	23/03/22	13/05/25	8,12	8,12	1-MO.	69,0	560,28	6	1,5	MEC.	
1	44	RB966928	4C	CB	23/03/22	13/05/25	3,64	3,64	1-MO.	69,0	251,16	6	1,5	MEC.	
1	45	RB966928	4C	CB	23/03/22	13/05/25	1,68	1,68	1-MO.	69,0	115,92	6	1,5	MEC.	
1	50	RB855453	4C	B	28/03/22	13/05/25	2,84	2,84	1-MO.	69,0	195,96	6	1,5	MEC.	
1	50	RB985476	4C	B	28/03/22	13/05/25	2,44	2,44	1-MO.	69,0	168,36	6	1,5	MEC.	
1	51	RB985476	4C	B	28/03/22	13/05/25	5,80	5,80	1-MO.	69,0	400,20	6	1,5	MEC.	
1	52	RB985476	4C	B	28/03/22	13/05/25	2,29	2,29	1-MO.	69,0	158,01	6	1,5	MEC.	
1	53	RB005014	4C	A	28/03/22	13/05/25	8,99	8,99	1-MO.	69,0	620,31	6	1,5	MEC.	
1	53	RB855453	4C	A	28/03/22	13/05/25	2,82	2,82	1-MO.	69,0	194,58	6	1,5	MEC.	
1	54	RB005014	4C	B	27/03/22	13/05/25	6,54	6,54	1-MO.	69,0	451,26	6	1,5	MEC.	
1	55	RB985476	4C	B	27/03/22	13/05/25	3,10	3,10	1-MO.	69,0	213,90	6	1,5	MEC.	
1	60	IACCTC07-7207	1C	C	15/02/25		1,97	1,97	1-MO.	130,0	256,10	6	1,5	MEC.	
1	61	IACCTC07-7207	1C	CB	15/02/25		0,08	0,08	1-MO.	130,0	10,40	6	1,5	MEC.	
1	62	RB985476	4C	A	24/03/22	13/05/25	3,05	3,05	1-MO.	67,0	204,35	6	1,5	MEC.	
1	63	RB985476	4C	C	24/03/22	13/05/25	10,04	10,04	1-MO.	67,0	672,68	6	1,5	MEC.	
1	64	RB985476	4C	C	24/03/22	13/05/25	2,26	2,26	1-MO.	67,0	151,42	6	1,5	MEC.	
1	65	RB985476	4C	B	27/03/22	13/05/25	3,83	3,83	1-MO.	67,0	256,61	6	1,5	MEC.	
1	66	RB985476	4C	B	23/03/22	13/05/25	4,19	4,19	1-MO.	67,0	280,73	6	1,5	MEC.	
1	67	RB966928	4C	B	24/03/22	13/05/25	1,13	1,13	1-MO.	67,0	75,71	6	1,5	MEC.	
1	68	RB966928	4C	B	24/03/22	13/05/25	0,61	0,61	1-MO.	67,0	40,87	6	1,5	MEC.	
1	69	RB966928	4C	B	23/03/22	13/05/25	1,01	1,01	1-MO.	67,0	67,67	6	1,5	MEC.	
1	69	RB985476	4C	B	23/03/22	13/05/25	3,99	3,99	1-MO.	67,0	267,33	6	1,5	MEC.	
1	70	RB966928	4C	B	23/03/22	13/05/25	9,24	9,24	1-MO.	67,0	619,08	6	1,5	MEC.	
1	71	RB966928	4C	B	23/03/22	13/05/25	13,72	13,72	1-MO.	67,0	919,24	6	1,5	MEC.	
1	72	RB966928	4C	B	23/03/22	13/05/25	9,04	9,04	1-MO.	67,0	605,68	6	1,5	MEC.	
1	84	IACSP01-5503	2C	C	28/11/23	23/05/25	9,94	9,94	1-MO.	95,0	944,30	6	1,5	MEC.	
1	85	IACSP01-5503	2C	A	19/11/23	23/05/25	10,65	10,65	1-MO.	95,0	1.011,75	6	1,5	MEC.	
1	86	IACSP01-5503	2C	A	26/11/23	23/05/25	4,99	4,99	1-MO.	95,0	474,05	6	1,5	MEC.	
1	87	RB867515	3C	C	13/04/23	13/05/25	1,74	1,74	1-MO.	65,0	113,10	6	1,5	MEC.	
1	88	RB867515	3C	C	13/04/23	13/05/25	4,85	4,85	1-MO.	65,0	315,25	6	1,5	MEC.	
1	89	RB867515	3C	C	12/04/23	13/05/25	1,79	1,79	1-MO.	65,0	116,35	6	1,5	MEC.	
1	90	RB867515	3C	C	12/04/23	13/05/25	1,64	1,64	1-MO.	65,0	106,60	6	1,5	MEC.	
1	91	RB867515	3C	C	12/04/23	13/05/25	2,40	2,40	1-MO.	65,0	156,00	6	1,5	MEC.	
1	92	RB867515	3C	C	13/04/23	13/05/25	3,77	3,77	1-MO.	65,0	245,05	6	1,5	MEC.	
1	93	RB867515	3C	C	12/04/23	13/05/25	1,29	1,29	1-MO.	65,0	83,85	6	1,5	MEC.	
Total/Média (1 / 5 · STA.ESMERIA)							276,33	276,33		79,2	21.873,99				

N: 7711888.191
E: 334605.0111
LAT: -20°41'7.9466" (-20.68554072)
LONG: -46°35'18.0596" (-46.58834988)

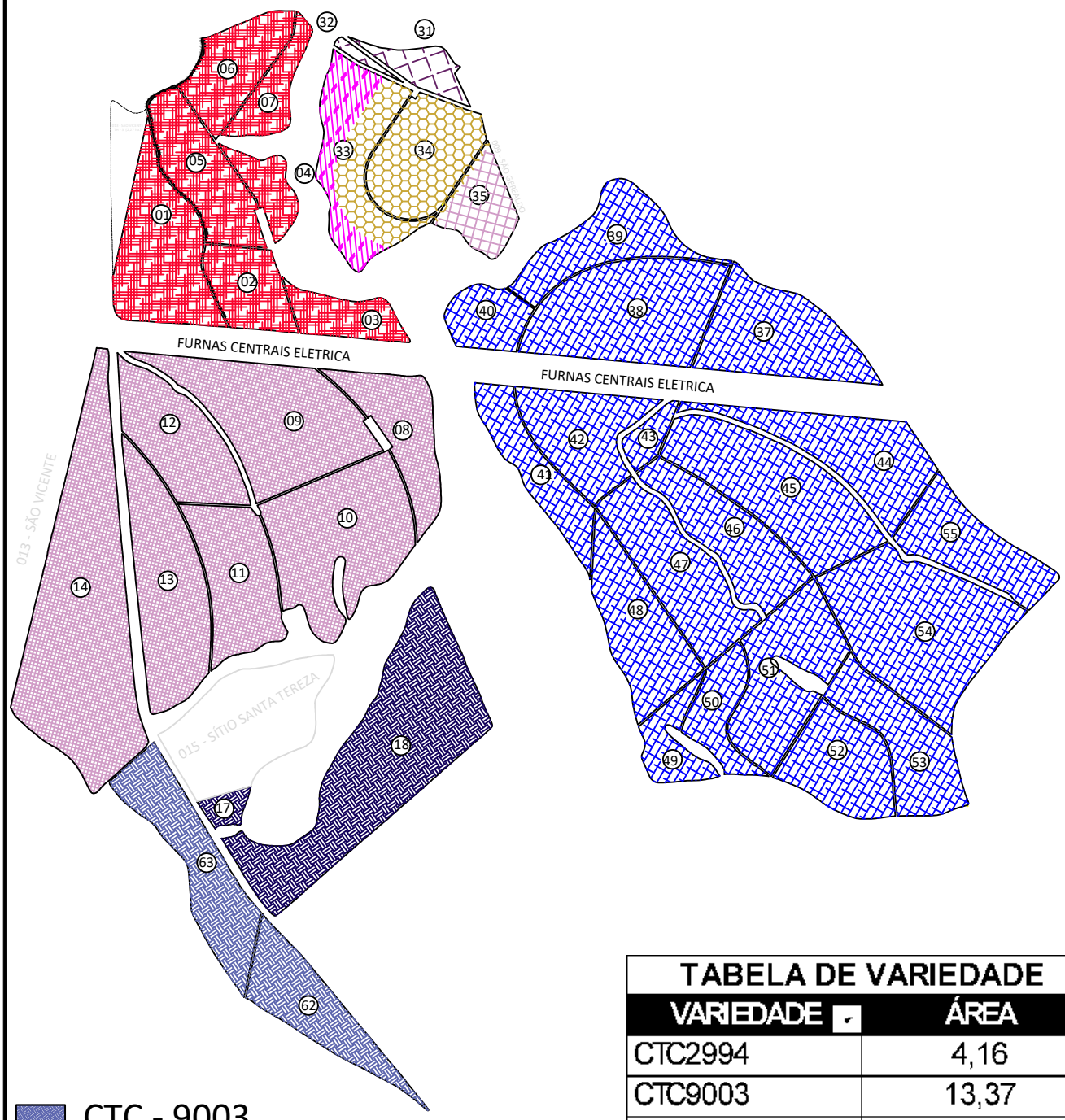

CTC - 9003
CTC - 9006
RB 98-7935
RB 97-5952
RB 12-7825
CTC 02-2994
IAC SP 01-5503
IAC CTC 07-7207

TABELA DE VARIEDADE

VARIEDADE	ÁREA
CTC2994	4,16
CTC9003	13,37
CTC9006	19,28
IACCTC07-7207	78,05
IACSP01-5503	31,06
RB127825	11,24
RB975952	2,45
RB987935	128,29
Total Geral	**287,90**

IPIRANGA AGROINDUSTRIAL

PROJETO: CADERNO DE MAPA 26'27	DATA: 23-12-2025	ESCALA: 1:5000	TOPÓGRAFO: CRISTIAN
FAZENDA: 006 - SANTA TEREZA	MUNICÍPIO: PASSOS MG		ÁREA (ha): 287,90
PROPRIETÁRIO: ITAIQUARA ALIMENTOS S.A	UNIDADE: IPIRANGA PASSOS		CÓDIGO: 006

Caderno de Mapas

Bloco	Talhao	Variedade	Estágio de Corte	Amb. Prod.	Data Plantio	Data Último Corte	Área (ha)	Estimativas Área (ha)	Estimativas Finalid	Estimativas Produt.	Prod. Total	Dist.	Esp.	Tipo Corte	Experimento
1 · REG 1			6 · STA.TEREZA				IPIRANGA AGROINDUSTRIAL S.A								
1	1	IACSP01-5503	3C	A	26/03/23	04/09/25	8,48	8,48	1-MO.	85,0	720,80	6	1,5	MEC.	
1	2	IACSP01-5503	3C	A	25/03/23	04/09/25	3,97	3,97	1-MO.	85,0	337,45	6	1,5	MEC.	
1	3	IACSP01-5503	3C	A	25/03/23	04/09/25	2,90	2,90	1-MO.	85,0	246,50	6	1,5	MEC.	
1	4	IACSP01-5503	3C	B	25/03/23	04/09/25	2,17	2,17	1-MO.	85,0	184,45	6	1,5	MEC.	
1	5	IACSP01-5503	3C	B	25/03/23	04/09/25	5,98	5,98	1-MO.	85,0	508,30	6	1,5	MEC.	
1	6	IACSP01-5503	3C	B	02/04/23	04/09/25	4,90	4,90	1-MO.	85,0	416,50	6	1,5	MEC.	
1	7	IACSP01-5503	3C	B	26/03/23	04/09/25	2,66	2,66	1-MO.	85,0	226,10	6	1,5	MEC.	
1	8	IACCTC07-7207	1C	A	15/02/25	24/04/26	5,43	5,43	1-MO.	130,0	705,90	6	1,5	MEC.	
1	9	IACCTC07-7207	1C	A	14/02/25	24/04/26	12,05	12,05	1-MO.	130,0	1.566,50	6	1,5	MEC.	
1	10	IACCTC07-7207	1C	A	15/02/25	24/04/26	12,05	12,05	1-MO.	130,0	1.566,50	6	1,5	MEC.	
1	11	IACCTC07-7207	1C	A	15/02/25	24/04/26	7,14	7,14	1-MO.	130,0	928,20	6	1,5	MEC.	
1	12	IACCTC07-7207	1C	A	15/02/25	24/04/26	7,14	7,14	1-MO.	130,0	928,20	6	1,5	MEC.	
1	13	IACCTC07-7207	1C	A	20/02/25	24/04/26	9,99	9,99	1-MO.	130,0	1.298,70	6	1,5	MEC.	
1	14	IACCTC07-7207	1C	B	17/02/25	30/04/26	20,97	20,97	1-MO.	130,0	2.726,10	6	1,5	MEC.	
1	17	CTC9006	1C	A	19/02/25	12/01/26	0,87	0,87	2-MU.	70,0	60,90	6	1,5	MEC.	
1	18	CTC9006	1C	A	19/02/25	12/01/26	18,41	18,41	2-MU.	70,0	1.288,70	6	1,5	MEC.	
1	31	RB975952	3C	A	29/07/23	12/09/25	2,08	2,08	1-MO.	85,0	176,80	6	1,5	MEC.	
1	32	RB975952	3C	A	29/07/23	12/09/25	0,37	0,37	1-MO.	85,0	31,45	6	1,5	MEC.	
1	33	CTC2994	3C	A	27/07/23	01/11/25	4,16	4,16	1-MO.	85,0	353,60	6	1,5	MEC.	
1	33	RB127825	3C	A	27/07/23	01/11/25	4,15	4,15	1-MO.	85,0	352,75	6	1,5	MEC.	
1	34	RB127825	3C	A	26/07/23	12/09/25	6,86	6,86	1-MO.	85,0	583,10	6	1,5	MEC.	
1	35	IACCTC07-7207	3C	A	25/07/23	12/09/25	3,28	3,28	1-MO.	85,0	278,80	6	1,5	MEC.	
1	35	RB127825	3C	A	25/07/23	12/09/25	0,23	0,23	1-MO.	85,0	19,55	6	1,5	MEC.	
1	37	RB987935	4C	BA	25/02/22	17/10/25	8,42	8,42	1-MO.	72,0	606,24	6	1,5	MEC.	
1	38	RB987935	4C	BA	28/02/22	17/10/25	11,41	11,41	1-MO.	72,0	821,52	6	1,5	MEC.	
1	39	RB987935	4C	A	26/02/22	17/10/25	6,16	6,16	1-MO.	72,0	443,52	6	1,5	MEC.	
1	40	RB987935	4C	A	26/02/22	17/10/25	3,01	3,01	1-MO.	72,0	216,72	6	1,5	MEC.	
1	41	RB987935	4C	A	27/02/22	17/10/25	4,63	4,63	1-MO.	72,0	333,36	6	1,5	MEC.	
1	42	RB987935	4C	BA	28/02/22	17/10/25	6,27	6,27	1-MO.	72,0	451,44	6	1,5	MEC.	
1	43	RB987935	4C	BA	26/02/22	17/10/25	1,23	1,23	1-MO.	72,0	88,56	6	1,5	MEC.	
1	44	RB987935	4C	BA	26/02/22	17/10/25	7,73	7,73	1-MO.	72,0	556,56	6	1,5	MEC.	
1	45	RB987935	4C	BA	10/02/22	17/10/25	11,00	11,00	1-MO.	72,0	792,00	6	1,5	MEC.	
1	46	RB987935	4C	BA	26/02/22	17/10/25	6,68	6,68	1-MO.	72,0	480,96	6	1,5	MEC.	
1	47	RB987935	4C	BA	28/02/22	17/10/25	7,98	7,98	1-MO.	72,0	574,56	6	1,5	MEC.	
1	48	RB987935	4C	BA	28/02/22	17/10/25	7,06	7,06	1-MO.	72,0	508,32	6	1,5	MEC.	
1	49	RB987935	4C	BA	27/02/22	17/10/25	2,63	2,63	1-MO.	72,0	189,36	6	1,5	MEC.	
1	50	RB987935	4C	BA	27/02/22	17/10/25	3,24	3,24	1-MO.	72,0	233,28	6	1,5	MEC.	
1	51	RB987935	4C	BA	26/02/22	17/10/25	8,18	8,18	1-MO.	72,0	588,96	6	1,5	MEC.	
1	52	RB987935	4C	BA	27/02/22	17/10/25	6,14	6,14	1-MO.	72,0	442,08	6	1,5	MEC.	

Caderno de Mapas

Bloco	Talhao	Variedade	Estágio de Corte	Amb. Prod.	Data Plantio	Data Último Corte	Área (ha)	Estimativas Área (ha)	Estimativas Finalid	Estimativas Produt.	Prod. Total	Dist.	Esp.	Tipo Corte	Experimento
1	53	RB987935	4C	BA	26/02/22	17/10/25	6,53	6,53	1-MO.	72,0	470,16	6	1,5	MEC.	
1	54	RB987935	4C	BA	28/02/22	17/10/25	13,94	13,94	1-MO.	72,0	1.003,68	6	1,5	MEC.	
1	55	RB987935	4C	BA	25/02/22	17/10/25	6,05	6,05	1-MO.	72,0	435,60	6	1,5	MEC.	
1	62	CTC9003	4C	A	19/01/22	05/11/25	5,79	5,79	1-MO.	55,0	318,45	6	1,5	MEC.	
1	63	CTC9003	4C	A	21/01/22	05/11/25	7,58	7,58	1-MO.	55,0	416,90	6	1,5	MEC.	
Total/Média (1 / 6 · STA.TEREZA)							287,90	287,90		88,5	25.478,08				

N: 7711888.191
E: 334605.0111
LAT: -20°41'7.9466" (-20.68554072)
LONG: -46°35'18.0596" (-46.58834988)

FURNAS CENTRAIS ELETRICA

50.0 0 50.0 100.0
METROS

N
W E
S

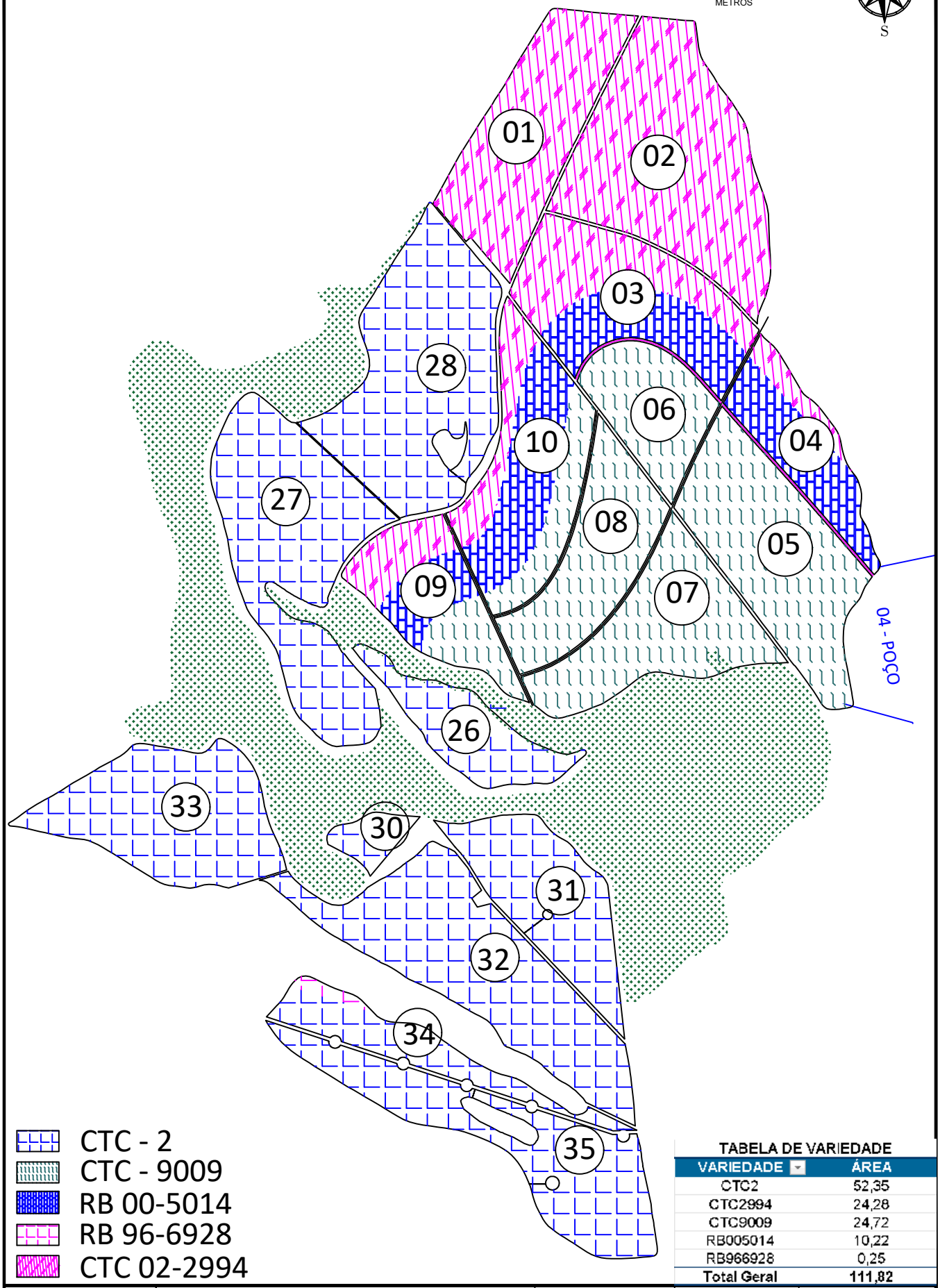

CTC - 2
CTC - 9009
RB 00-5014
RB 96-6928
CTC 02-2994

TABELA DE VARIEDADE

VARIEDADE	ÁREA
CTC2	52,35
CTC2994	24,28
CTC9009	24,72
RB005014	10,22
RB966928	0,25
Total Geral	**111,82**

IPIRANGA AGROINDUSTRIAL

PROJETO: CADERNO DE MAPA 26'27	DATA: 23-12-2025	ESCALA: 1:5000	TOPÓGRAFO: CRISTIAN
FAZENDA: 007 - SANTO ANTONIO	MUNICÍPIO: PASSOS MG		ÁREA (ha): 111,82
PROPRIETÁRIO: ITAIQUARA ALIMENTOS S.A	UNIDADE: IPIRANGA PASSOS		CÓDIGO: 007

Caderno de Mapas

Bloco	Talhao	Variedade	Estágio de Corte	Amb. Prod.	Data Plantio	Último Corte	Área (ha)	Estimativas Área (ha)	Finalid	Produt.	Prod. Total	Dist.	Esp.	Tipo Corte	Experimento
1 · REG 1			**7 · STO.ANTONIO I**				**IPIRANGA AGROINDUSTRIAL S.A**								
1	1	CTC2994	3C	BA	17/10/23	17/04/26	6,60	6,60	1-MO.	110,0	726,00	9	1,5	MEC.	
1	2	CTC2994	3C	BA	29/10/23	17/04/26	10,05	10,05	1-MO.	110,0	1.105,50	9	1,5	MEC.	
1	3	CTC2994	2C	A	06/11/23	17/04/26	3,93	3,93	1-MO.	110,0	432,30	9	1,5	MEC.	
1	3	RB005014	2C	A	06/11/23	17/04/26	2,78	2,78	1-MO.	110,0	305,80	9	1,5	MEC.	
1	4	CTC2994	2C	A	06/11/23	17/04/26	0,69	0,69	1-MO.	100,0	69,00	9	1,5	MEC.	
1	4	RB005014	2C	A	06/11/23	17/04/26	2,78	2,78	1-MO.	100,0	278,00	9	1,5	MEC.	
1	5	CTC9009	2C	A	04/03/24	17/04/26	7,35	7,35	1-MO.	100,0	735,00	9	1,5	MEC.	
1	6	CTC9009	2C	A	04/03/24	17/04/26	3,44	3,44	1-MO.	100,0	344,00	9	1,5	MEC.	
1	7	CTC9009	2C	A	04/04/24	17/04/26	5,86	5,86	1-MO.	100,0	586,00	9	1,5	MEC.	
1	8	CTC9009	2C	A	04/03/24	17/04/26	4,80	4,80	1-MO.	100,0	480,00	9	1,5	MEC.	
1	9	CTC2994	2C	A	12/12/23	17/04/26	1,43	1,43	1-MO.	100,0	143,00	9	1,5	MEC.	
1	9	CTC9009	2C	A	12/12/23	17/04/26	1,42	1,42	1-MO.	100,0	142,00	9	1,5	MEC.	
1	9	RB005014	2C	A	12/12/23	17/04/26	1,36	1,36	1-MO.	100,0	136,00	9	1,5	MEC.	
1	10	CTC2994	2C	A	20/11/23	17/04/26	1,58	1,58	1-MO.	105,0	165,90	9	1,5	MEC.	
1	10	CTC9009	2C	A	20/11/23	17/04/26	1,85	1,85	1-MO.	105,0	194,25	9	1,5	MEC.	
1	10	RB005014	2C	A	20/11/23	17/04/26	3,30	3,30	1-MO.	105,0	346,50	9	1,5	MEC.	
1	26	CTC2	5C	A	27/04/21	31/10/25	3,07	3,07	1-MO.	58,0	178,06	9	1,5	MEC.	
1	27	CTC2	5C	A	27/04/21	31/10/25	9,09	9,09	1-MO.	58,0	527,22	9	1,5	MEC.	
1	28	CTC2	5C	A	26/04/21	31/10/25	9,65	9,65	1-MO.	58,0	559,70	9	1,5	MEC.	
1	30	CTC2	5C	A	28/04/21	31/10/25	0,83	0,83	1-MO.	58,0	48,14	9	1,5	MEC.	
1	31	CTC2	5C	A	27/04/21	31/10/25	4,86	4,86	1-MO.	58,0	281,88	9	1,5	MEC.	
1	32	CTC2	5C	A	27/04/21	31/10/25	9,00	9,00	1-MO.	58,0	522,00	9	1,5	MEC.	
1	33	CTC2	5C	BA	27/04/21	31/10/25	6,87	6,87	1-MO.	58,0	398,46	9	1,5	MEC.	
1	34	CTC2	5C	A	29/04/21	31/10/25	2,54	2,54	1-MO.	58,0	147,32	9	1,5	MEC.	
1	34	RB966928	5C	A	29/04/21	31/10/25	0,25	0,25	1-MO.	58,0	14,50	9	1,5	MEC.	
1	35	CTC2	5C	A	28/04/21	31/10/25	6,44	6,44	1-MO.	58,0	373,52	9	1,5	MEC.	
Total/Média (1 / 7 · STO.ANTONIO I)							111,82	111,82		82,6	9.240,05				

N: 7711888.191
E: 334605.0111
LAT: -20°41'7.9466" (-20.68554072)
LONG: -46°35'18.0596" (-46.58834988)

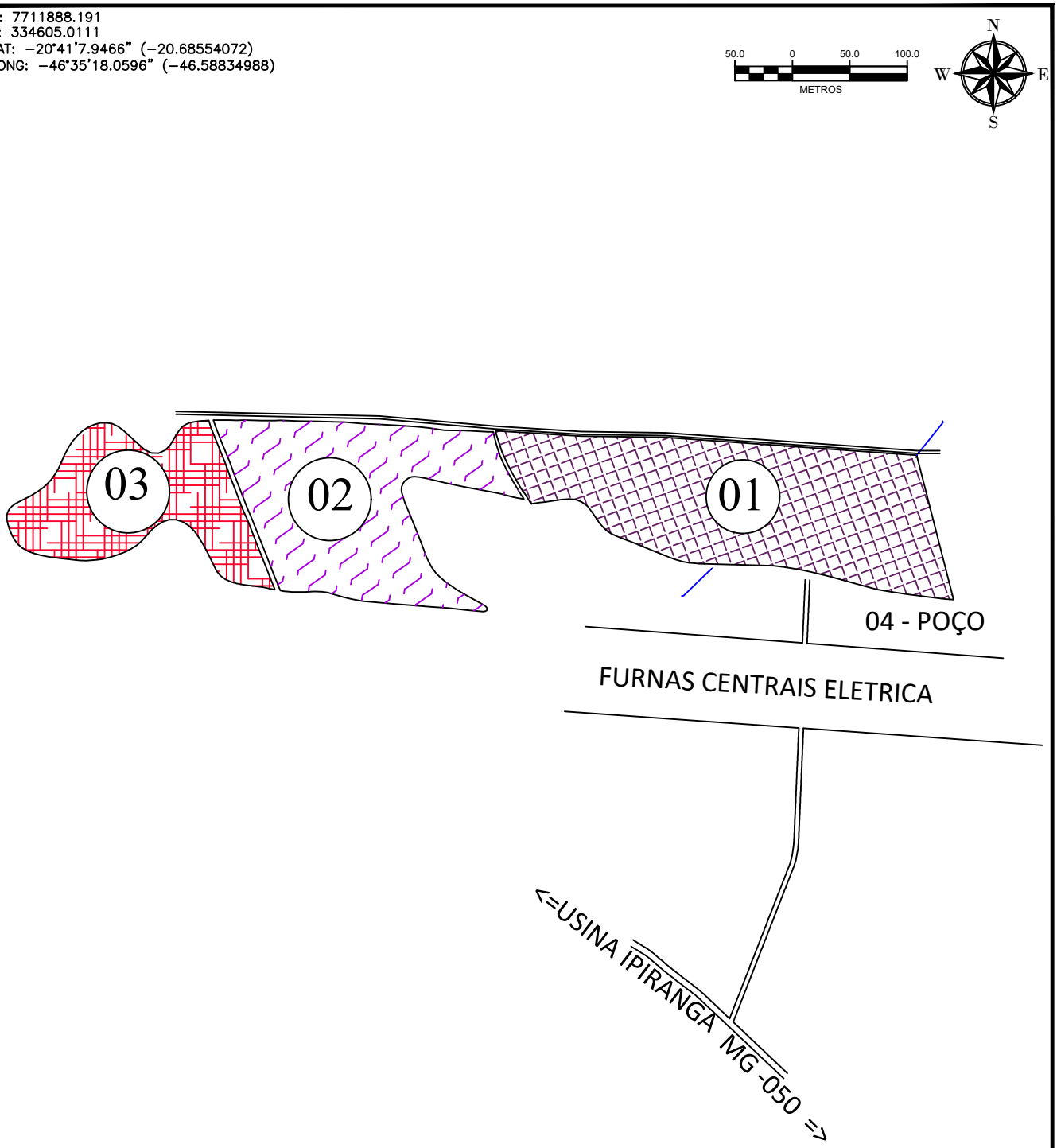

CTC - 9007
RB 97-5952
IAC SP 01-5503

TABELA DE VARIEDADE

VARIEDADE	ÁREA
CTC9007	4,24
IACSP01-5503	2,86
RB975952	5,61
Total Geral	**12,71**

IPIRANGA AGROINDUSTRIAL

PROJETO: CADERNO DE MAPA 26'27	DATA: 23-12-2025	ESCALA: 1:5000	TOPÓGRAFO: CRISTIAN
FAZENDA: 008 - SÃO DOMINGOS	MUNICÍPIO: PASSOS MG		ÁREA (ha): 12,71
PROPRIETÁRIO: ITAIQUARA ALIMENTOS S.A	UNIDADE: IPIRANGA PASSOS		ÁREA (ha): 008

Caderno de Mapas

Bloco	Talhao	Variedade	Estágio de Corte	Amb. Prod.	Data Plantio	Último Corte	Área (ha)	Estimativas Área (ha)	Finalid	Produt.	Prod. Total	Dist.	Esp.	Tipo Corte	Experimento
1 · REG 1			**8 · S.DOMINGOS**				**IPIRANGA AGROINDUSTRIAL S.A**								
1	1	RB975952	4C	A	29/12/21	10/10/25	5,61	5,61	1-MO.	55,0	308,55	10	1,5	MEC.	
1	2	CTC9007	3C	A	18/07/23	10/10/25	4,24	4,24	1-MO.	65,0	275,60	10	1,5	MEC.	
1	3	IACSP01-5503	3C	A	20/06/23	10/10/25	2,86	2,86	1-MO.	65,0	185,90	10	1,5	MEC.	
Total/Média (1 / 8 · S.DOMINGOS)							12,71	12,71		60,6	770,05				

N: 7710106.37736650
E: 341344.52906282
LAT: −20°42'7.9903433" (−20.70221953982)
LONG: −46°31'25.7578793" (−46.52382163314)

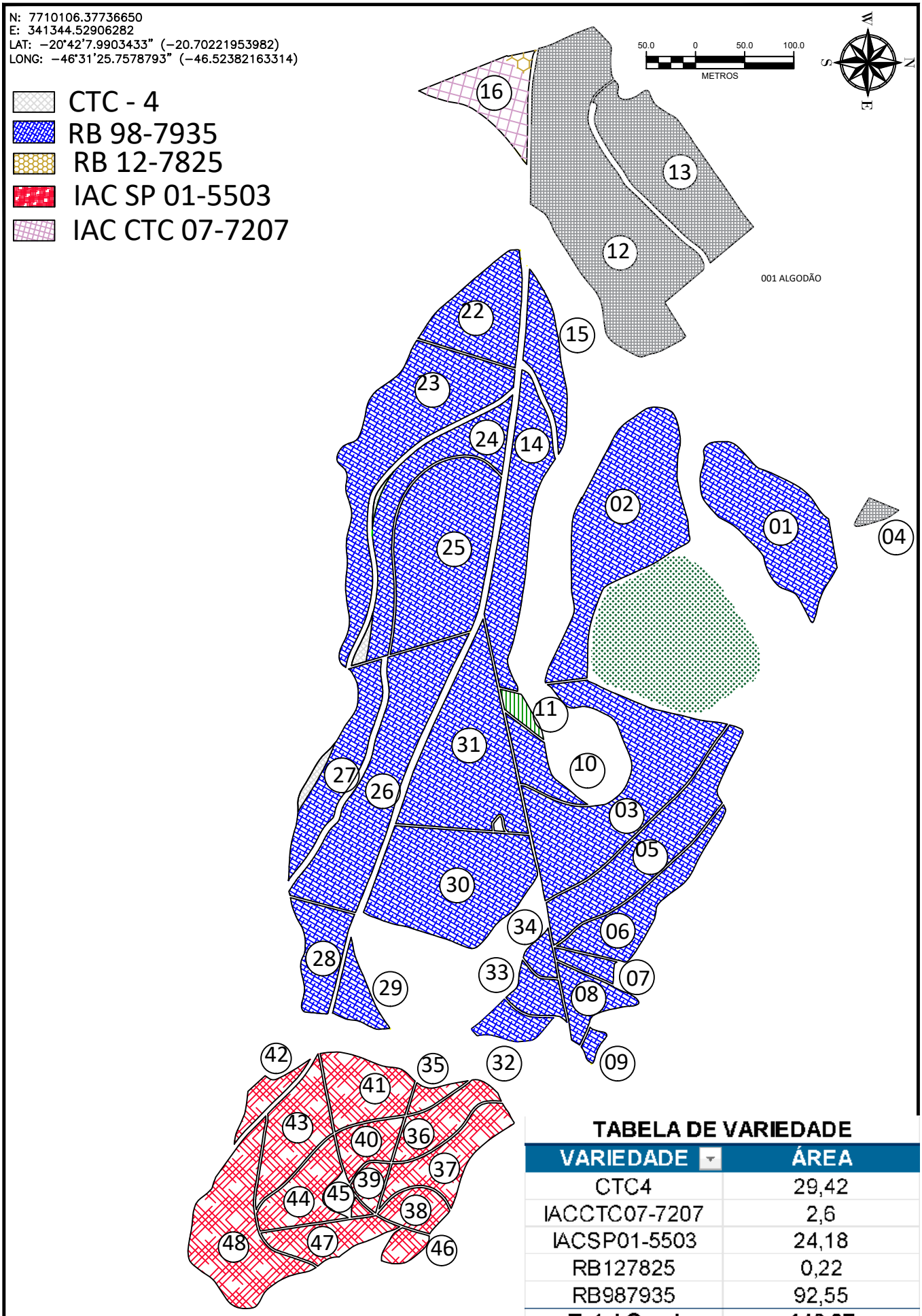

TABELA DE VARIEDADE

VARIEDADE	ÁREA
CTC4	29,42
IACCTC07-7207	2,6
IACSP01-5503	24,18
RB127825	0,22
RB987935	92,55
Total Geral	**148,97**

IPIRANGA AGROINDUSTRIAL

PROJETO: CADERNO DE MAPA 26'27	DATA: 23-12-2025	ESCALA: 1:5000	TOPÓGRAFO: CRISTIAN
FAZENDA: 009 - SÃO GERALDO	MUNICÍPIO: PASSOS MG		ÁREA (ha): 148,97
PROPRIETÁRIO: IPIRANGA AGROINDUSTRIAL	UNIDADE: IPIRANGA PASSOS MG		CÓDIGO: 009

Caderno de Mapas

Bloco	Talhao	Variedade	Estágio de Corte	Amb. Prod.	Data Plantio	Último Corte	Área (ha)	Estimativas Área (ha)	Finalid	Produt.	Prod. Total	Dist.	Esp.	Tipo Corte	Experimento
1 · REG 1			9 · S.GERALDO				IPIRANGA AGROINDUSTRIAL S.A								
1	1	RB987935	4C	A	17/04/22	12/09/25	6,31	6,31	1-MO.	72,0	454,32	8,5	1,5	MEC.	
1	2	RB987935	4C	A	17/04/22	01/10/25	9,31	9,31	1-MO.	72,0	670,32	8,5	1,5	MEC.	
1	3	RB987935	4C	B	18/04/22	01/10/25	8,89	8,89	1-MO.	72,0	640,08	8,5	1,5	MEC.	
1	4	CTC4	5C	A	15/11/21	12/09/25	0,34	0,34	1-MO.	72,0	24,48	8,5	1,5	MEC.	
1	5	RB987935	4C	B	17/04/22	01/10/25	5,19	5,19	1-MO.	72,0	373,68	8,5	1,5	MEC.	
1	6	RB987935	4C	D	17/04/22	01/10/25	2,86	2,86	1-MO.	72,0	205,92	8,5	1,5	MEC.	
1	7	RB987935	4C	B	17/04/22	01/10/25	0,53	0,53	1-MO.	72,0	38,16	8,5	1,5	MEC.	
1	8	RB987935	4C	B	18/04/22	01/10/25	1,48	1,48	1-MO.	72,0	106,56	8,5	1,5	MEC.	
1	9	RB987935	4C	B	18/04/22	01/10/25	0,25	0,25	1-MO.	72,0	18,00	8,5	1,5	MEC.	
1	10	RB987935	4C	B	18/04/22	01/10/25	1,27	1,27	1-MO.	72,0	91,44	8,5	1,5	MEC.	
1	11	RB987935	4C	A	18/04/22	01/10/25	0,44	0,44	1-MO.	72,0	31,68	8,5	1,5	MEC.	
1	12	CTC4	5C	A	15/11/21	12/09/25	14,28	14,28	1-MO.	72,0	1.028,16	8,5	1,5	MEC.	
1	13	CTC4	5C	A	16/11/21	12/09/25	6,63	6,63	1-MO.	72,0	477,36	8,5	1,5	MEC.	
1	14	RB987935	4C	A	28/02/22	01/10/25	4,91	4,91	1-MO.	72,0	353,52	8,5	1,5	MEC.	
1	15	RB987935	4C	B	28/02/22	01/10/25	2,05	2,05	1-MO.	72,0	147,60	8,5	1,5	MEC.	
1	16	IACCTC07-7207	3C	A	25/07/23	12/09/25	2,60	2,60	1-MO.	82,0	213,20	8,5	1,5	MEC.	
1	16	RB127825	3C	A	25/07/23	12/09/25	0,22	0,22	1-MO.	82,0	18,04	8,5	1,5	MEC.	
1	22	RB987935	4C	B	08/03/22	01/10/25	3,72	3,72	1-MO.	75,0	279,00	8,5	1,5	MEC.	
1	23	RB987935	4C	B	07/03/22	01/10/25	8,10	8,10	1-MO.	75,0	607,50	8,5	1,5	MEC.	
1	24	CTC4	4C	B	03/03/22	01/10/25	0,27	0,27	1-MO.	75,0	20,25	8,5	1,5	MEC.	
1	24	RB987935	4C	B	03/03/22	01/10/25	3,93	3,93	1-MO.	75,0	294,75	8,5	1,5	MEC.	
1	25	RB987935	4C	A	03/03/22	01/10/25	8,50	8,50	1-MO.	75,0	637,50	8,5	1,5	MEC.	
1	26	CTC4	4C	A	04/03/22	01/10/25	7,63	7,63	1-MO.	75,0	572,25	8,5	1,5	MEC.	
1	27	CTC4	4C	A	06/03/22	01/10/25	0,27	0,27	1-MO.	75,0	20,25	8,5	1,5	MEC.	
1	27	RB987935	4C	A	06/03/22	01/10/25	3,18	3,18	1-MO.	75,0	238,50	8,5	1,5	MEC.	
1	28	RB987935	4C	A	08/03/22	01/10/25	2,27	2,27	1-MO.	75,0	170,25	8,5	1,5	MEC.	
1	29	RB987935	4C	A	12/03/22	01/10/25	1,13	1,13	1-MO.	75,0	84,75	8,5	1,5	MEC.	
1	30	RB987935	4C	B	08/03/22	01/10/25	8,07	8,07	1-MO.	75,0	605,25	8,5	1,5	MEC.	
1	31	RB987935	4C	A	01/03/22	01/10/25	7,68	7,68	1-MO.	75,0	576,00	8,5	1,5	MEC.	
1	32	RB987935	4C	B	21/04/22	01/10/25	0,95	0,95	1-MO.	75,0	71,25	8,5	1,5	MEC.	
1	33	RB987935	4C	B	21/04/22	01/10/25	1,01	1,01	1-MO.	75,0	75,75	8,5	1,5	MEC.	
1	34	RB987935	4C	B	19/04/22	01/10/25	0,52	0,52	1-MO.	75,0	39,00	8,5	1,5	MEC.	
1	35	IACSP01-5503	3C	CB	17/06/23	10/10/25	0,43	0,43	1-MO.	84,0	36,12	8,5	1,5	MEC.	
1	36	IACSP01-5503	3C	A	17/06/23	10/10/25	1,83	1,83	1-MO.	84,0	153,72	8,5	1,5	MEC.	
1	37	IACSP01-5503	3C	A	17/06/23	10/10/25	2,47	2,47	1-MO.	84,0	207,48	8,5	1,5	MEC.	
1	38	IACSP01-5503	3C	A	19/06/23	10/10/25	1,12	1,12	1-MO.	84,0	94,08	8,5	1,5	MEC.	
1	39	IACSP01-5503	3C	A	19/06/23	10/10/25	0,61	0,61	1-MO.	84,0	51,24	8,5	1,5	MEC.	
1	40	IACSP01-5503	3C	A	16/06/23	10/10/25	1,31	1,31	1-MO.	84,0	110,04	8,5	1,5	MEC.	
1	41	IACSP01-5503	3C	CB	16/06/23	10/10/25	2,68	2,68	1-MO.	84,0	225,12	8,5	1,5	MEC.	

Caderno de Mapas

Bloco	Talhao	Variedade	Estágio de Corte	Amb. Prod.	Data Plantio	Data Último Corte	Área (ha)	Estimativas Área (ha)	Estimativas Finalid	Estimativas Produt.	Prod. Total	Dist.	Esp.	Tipo Corte	Experimento
1	42	IACSP01-5503	3C	CB	16/06/23	10/10/25	0,79	0,79	1-MO.	84,0	66,36	8,5	1,5	MEC.	
1	43	IACSP01-5503	3C	CB	17/06/23	10/10/25	2,92	2,92	1-MO.	84,0	245,28	8,5	1,5	MEC.	
1	44	IACSP01-5503	3C	CB	16/06/23	10/10/25	2,19	2,19	1-MO.	84,0	183,96	8,5	1,5	MEC.	
1	45	IACSP01-5503	3C	A	19/06/23	10/10/25	0,11	0,11	1-MO.	84,0	9,24	8,5	1,5	MEC.	
1	46	IACSP01-5503	3C	A	19/06/23	10/10/25	0,60	0,60	1-MO.	84,0	50,40	8,5	1,5	MEC.	
1	47	IACSP01-5503	3C	A	17/06/23	10/10/25	1,83	1,83	1-MO.	84,0	153,72	8,5	1,5	MEC.	
1	48	IACSP01-5503	3C	CB	15/06/23	10/10/25	5,29	5,29	1-MO.	84,0	444,36	8,5	1,5	MEC.	
Total/Média (1 / 9 · S.GERALDO)							148,97	148,97		75,3	11.215,89				

N: 7708093.430
E: 337086.1212
LAT: −20°43'12.1262" (−20.72003505)
LONG: −46°33'53.5934" (−46.56488707)

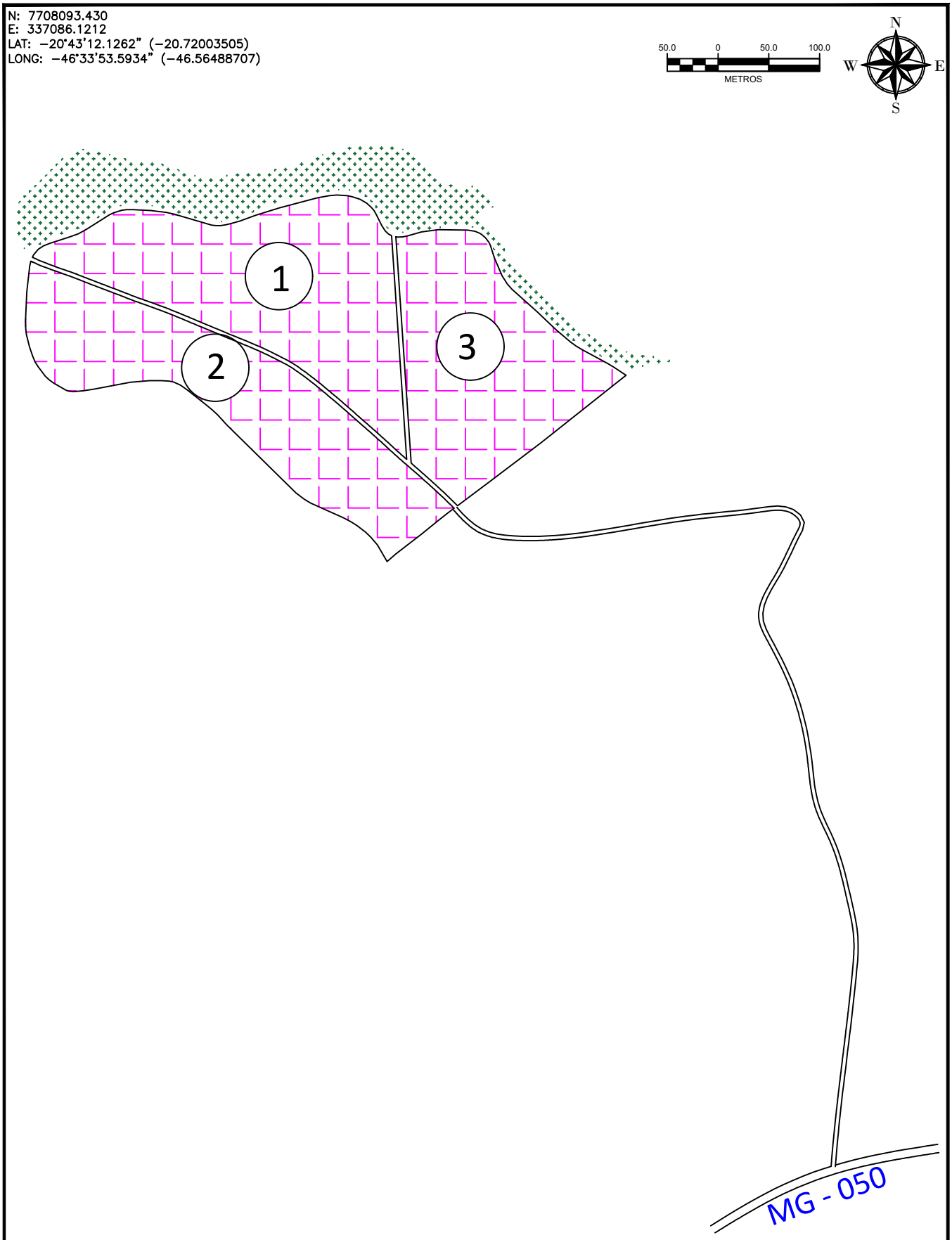

RB 96-6928

TABELA DE VARIEDADE

VARIEDADE	ÁREA
RB966928	16,86
Total Geral	**16,86**

IPIRANGA AGROINDUSTRIAL

PROJETO: CADERNO DE MAPA 26'27	DATA: 24-12-2025	ESCALA: 1:5000	TOPÓGRAFO: CRISTIAN
FAZENDA: 010 - SÃO JOAQUIM	MUNICÍPIO: PASSOS MG		ÁREA (ha): 16,86
PROPRIETÁRIO: ITAIQUARA ALIMENTOS S.A	UNIDADE: IPIRANGA PASSOS		CÓDIGO: 010

Caderno de Mapas

Bloco	Talhao	Variedade	Estágio de Corte	Amb. Prod.	Data Plantio	Último Corte	Área (ha)	Estimativas Área (ha)	Finalid	Produt.	Prod. Total	Dist.	Esp.	Tipo Corte	Experimento
1 · REG 1			**10 · S.JOAQUIM**				**IPIRANGA AGROINDUSTRIAL S.A**								
1	1	RB966928	4C	B	07/04/22	25/03/26	6,22	6,22	1-MO.	68,0	422,96	11,3	1,5	MEC.	
1	2	RB966928	4C	B	07/04/22	25/03/26	5,55	5,55	1-MO.	68,0	377,40	11,3	1,5	MEC.	
1	3	RB966928	4C	CB	07/04/22	25/03/26	5,09	5,09	1-MO.	68,0	346,12	11,3	1,5	MEC.	
Total/Média (1 / 10 · S.JOAQUIM)							16,86	16,86		68,0	1.146,48				

N: 7708093.430
E: 337086.1212
LAT: −20°43'12.1262" (−20.72003505)
LONG: −46°33'53.5934" (−46.56488707)

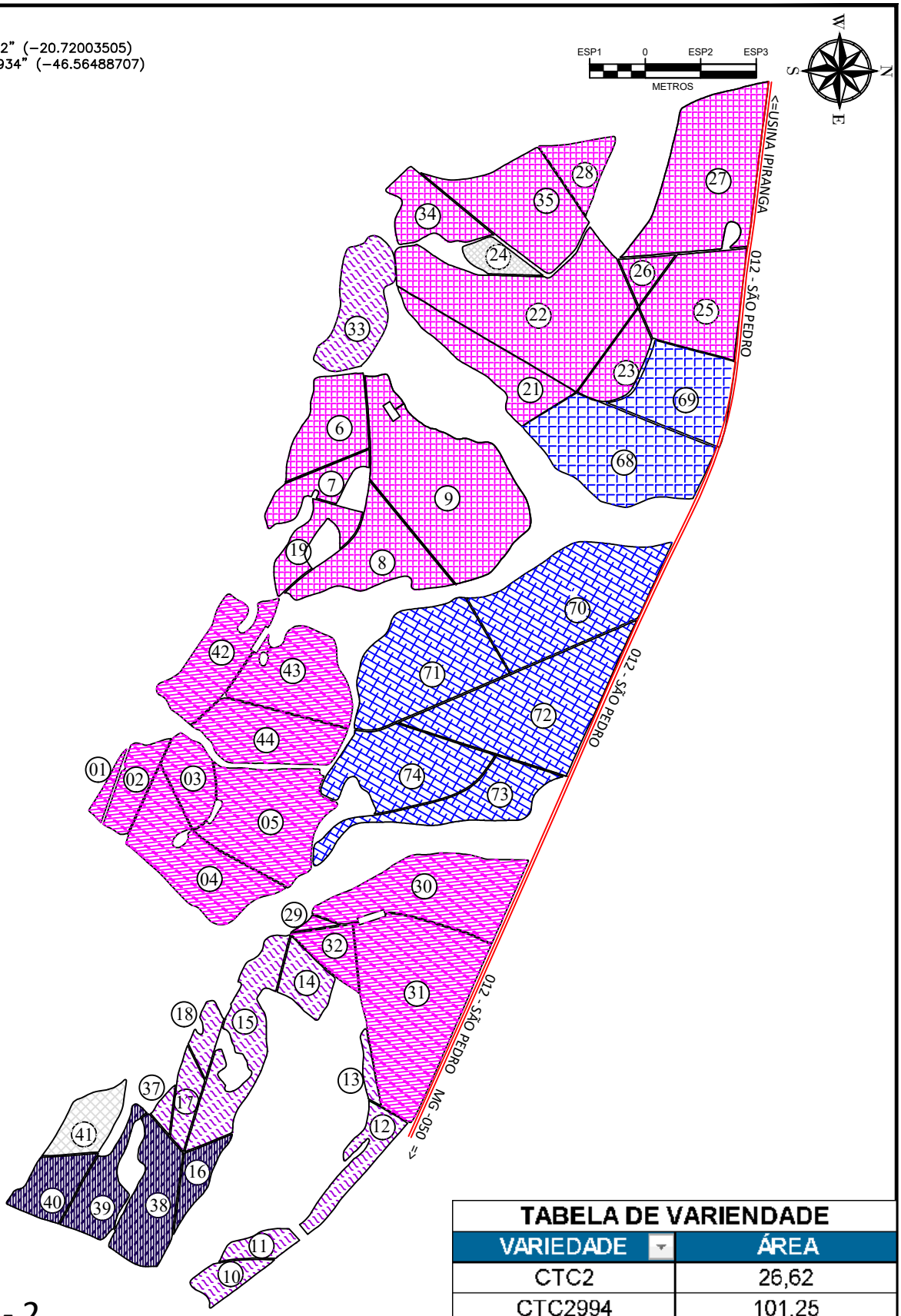

CTC - 2
CTC - 4
CTC -2994
CTC - 9007
CV-7870
RB 96-6928
RB 98-7935

TABELA DE VARIENDADE

VARIEDADE	ÁREA
CTC2	26,62
CTC2994	101,25
CTC4	6,43
CTC9007	35,35
CV7870	19,97
RB966928	137,91
RB987935	74,74
TOTAL	**402,27**

IPIRANGA AGROINDUSTRIAL

PROJETO: CADERNO DE MAPA 26'27	DATA: 30-12-2025	ESCALA: 1:5000	TOPÓGRAFO: CRISTIAN
FAZENDA: 011 - SÃO JOSÉ	MUNICÍPIO: PASSOS MG		ÁREA (ha): 402,27
PROPRIETÁRIO: ITAIQUARA ALIMENTOS S.A	UNIDADE: IPIRANGA PASSOS		CÓDIGO: 011

Caderno de Mapas

Bloco	Talhao	Variedade	Estágio de Corte	Amb. Prod.	Data Plantio	Último Corte	Área (ha)	Estimativas Área (ha)	Finalid	Produt.	Prod. Total	Dist.	Esp.	Tipo Corte	Experimento
1 · REG 1			11 · S.JOSE				IPIRANGA AGROINDUSTRIAL S.A								
1	1	CTC2994	1IN	A	30/08/25		0,81	0,81	1-MO.	100,0	81,00	8,3	1,5	MEC.	
1	2	CTC2994	1IN	A	30/08/25		3,67	3,67	1-MO.	100,0	367,00	8,3	1,5	MEC.	
1	3	CTC2994	1IN	BA	29/08/25		4,25	4,25	1-MO.	100,0	425,00	8,3	1,5	MEC.	
1	4	CTC2994	1IN	A	28/08/25		11,71	11,71	1-MO.	100,0	1.171,00	8,3	1,5	MEC.	
1	5	CTC2994	1IN	A	27/08/25		13,86	13,86	1-MO.	100,0	1.386,00	8,3	1,5	MEC.	
1	6	RB966928	4C	A	28/12/21	04/07/25	7,44	7,44	1-MO.	85,0	632,40	8,3	1,5	MEC.	
1	7	RB966928	4C	A	13/01/22	04/07/25	3,73	3,73	1-MO.	85,0	317,05	8,3	1,5	MEC.	
1	8	RB966928	4C	A	21/01/22	04/07/25	9,54	9,54	1-MO.	85,0	810,90	8,3	1,5	MEC.	
1	9	RB966928	4C	A	20/01/22	04/07/25	23,71	23,71	1-MO.	85,0	2.015,35	8,3	1,5	MEC.	
1	10	CTC9007	3C	A	28/03/23	16/07/25	2,48	2,48	1-MO.	85,0	210,80	8,3	1,5	MEC.	
1	11	CTC9007	3C	A	28/03/23	16/07/25	2,04	2,04	1-MO.	85,0	173,40	8,3	1,5	MEC.	
1	12	CTC9007	3C	A	29/03/23	16/07/25	4,23	4,23	1-MO.	85,0	359,55	8,3	1,5	MEC.	
1	13	CTC9007	3C	A	29/03/23	16/07/25	0,90	0,90	1-MO.	85,0	76,50	8,3	1,5	MEC.	
1	14	CTC9007	3C	A	29/03/23	03/10/25	3,42	3,42	1-MO.	85,0	290,70	8,3	1,5	MEC.	
1	15	CTC9007	3C	A	29/03/23	03/10/25	9,16	9,16	1-MO.	80,0	732,80	8,3	1,5	MEC.	
1	16	CV7870	3C	CB	28/03/23	03/10/25	2,59	2,59	1-MO.	80,0	207,20	8,3	1,5	MEC.	
1	17	CTC9007	3C	A	31/03/23	03/10/25	2,44	2,44	1-MO.	80,0	195,20	8,3	1,5	MEC.	
1	18	CTC9007	3C	A	31/03/23	03/10/25	1,74	1,74	1-MO.	80,0	139,20	8,3	1,5	MEC.	
1	19	RB966928	4C	A	20/01/22	04/07/25	3,67	3,67	1-MO.	80,0	293,60	8,3	1,5	MEC.	
1	21	RB966928	5C	A	01/04/21	30/06/25	8,00	8,00	1-MO.	75,0	600,00	8,3	1,5	MEC.	
1	22	RB966928	6C	A	29/03/21	30/06/25	24,27	24,27	1-MO.	60,0	1.456,20	8,3	1,5	MEC.	
1	23	RB966928	5C	A	25/03/21	30/06/25	4,20	4,20	1-MO.	70,0	294,00	8,3	1,5	MEC.	
1	24	CTC4	5C	A	29/03/21	30/06/25	2,18	2,18	1-MO.	70,0	152,60	8,3	1,5	MEC.	
1	25	RB966928	5C	A	22/03/21	30/06/25	10,95	10,95	1-MO.	70,0	766,50	8,3	1,5	MEC.	
1	26	RB966928	5C	A	24/03/21	30/06/25	1,76	1,76	1-MO.	70,0	123,20	8,3	1,5	MEC.	
1	27	RB966928	5C	A	26/03/21	30/06/25	19,05	19,05	1-MO.	75,0	1.428,75	8,3	1,5	MEC.	
1	28	RB966928	5C	A	05/04/21	30/06/25	3,70	3,70	1-MO.	75,0	277,50	8,3	1,5	MEC.	
1	29	CTC2994	1IN	A	13/08/25		0,41	0,41	1-MO.	90,0	36,90	8,3	1,5	MEC.	
1	30	CTC2994	1IN	A	16/08/25		13,97	13,97	1-MO.	90,0	1.257,30	8,3	1,5	MEC.	
1	31	CTC2994	1IN	A	18/08/25		22,46	22,46	1-MO.	90,0	2.021,40	8,3	1,5	MEC.	
1	32	CTC2994	1IN	A	22/09/25		2,97	2,97	1-MO.	90,0	267,30	8,3	1,5	MEC.	
1	33	CTC9007	3C	A	29/03/23	04/07/25	8,22	8,22	1-MO.	100,0	822,00	8,3	1,5	MEC.	
1	34	RB966928	4C	A	01/02/22	30/06/25	5,47	5,47	1-MO.	76,0	415,72	8,3	1,5	MEC.	
1	35	RB966928	4C	A	26/01/22	30/06/25	12,42	12,42	1-MO.	76,0	943,92	8,3	1,5	MEC.	
1	37	CTC9007	3C	A	29/03/23	03/10/25	0,72	0,72	1-MO.	79,0	56,88	8,3	1,5	MEC.	
1	38	CV7870	3C	CB	29/03/23	03/10/25	7,99	7,99	1-MO.	79,0	631,21	8,3	1,5	MEC.	
1	39	CV7870	3C	CB	31/03/23	03/10/25	4,95	4,95	1-MO.	79,0	391,05	8,3	1,5	MEC.	
1	40	CV7870	3C	CB	01/04/23	03/10/25	4,44	4,44	1-MO.	79,0	350,76	8,3	1,5	MEC.	
1	41	CTC4	3C	CB	27/03/23	03/10/25	4,25	4,25	1-MO.	79,0	335,75	8,3	1,5	MEC.	

Caderno de Mapas

Bloco	Talhao	Variedade	Estágio de Corte	Amb. Prod.	Data Plantio	Data Último Corte	Área (ha)	Estimativas Área (ha)	Estimativas Finalid	Estimativas Produt.	Prod. Total	Dist.	Esp.	Tipo Corte	Experimento
1	42	CTC2994	1IN	A	19/09/25		8,09	8,09	1-MO.	90,0	728,10	8,3	1,5	MEC.	
1	43	CTC2994	1IN	A	24/09/25		10,12	10,12	1-MO.	90,0	910,80	8,3	1,5	MEC.	
1	44	CTC2994	1IN	A	27/09/25		8,93	8,93	1-MO.	90,0	803,70	8,3	1,5	MEC.	
1	68	CTC2	5C	A	24/11/21	30/06/25	16,70	16,70	1-MO.	80,0	1.336,00	8,3	1,5	MEC.	
1	69	CTC2	5C	A	21/11/21	30/06/25	9,92	9,92	1-MO.	80,0	793,60	8,3	1,5	MEC.	
1	70	RB987935	4C	A	06/12/21	18/05/26	19,07	19,07	1-MO.	60,0	1.144,20	8,3	1,5	MEC.	
1	71	RB987935	4C	A	29/12/21	18/05/26	16,09	16,09	1-MO.	60,0	965,40	8,3	1,5	MEC.	
1	72	RB987935	4C	A	06/03/22	18/05/26	19,30	19,30	1-MO.	60,0	1.158,00	8,3	1,5	MEC.	
1	73	RB987935	4C	A	07/02/22	18/05/26	8,19	8,19	1-MO.	60,0	491,40	8,3	1,5	MEC.	
1	74	RB987935	4C	A	09/01/22	18/05/26	12,09	12,09	1-MO.	60,0	725,40	8,3	1,5	MEC.	
Total/Média (1 / 11 · S.JOSE)							402,27	402,27		78,5	31.570,19				

N: 7712877.780
E: 345055.1634
LAT: −20°40'38.9900" (−20.67749721)
LONG: −46°29'16.6430" (−46.48795638)

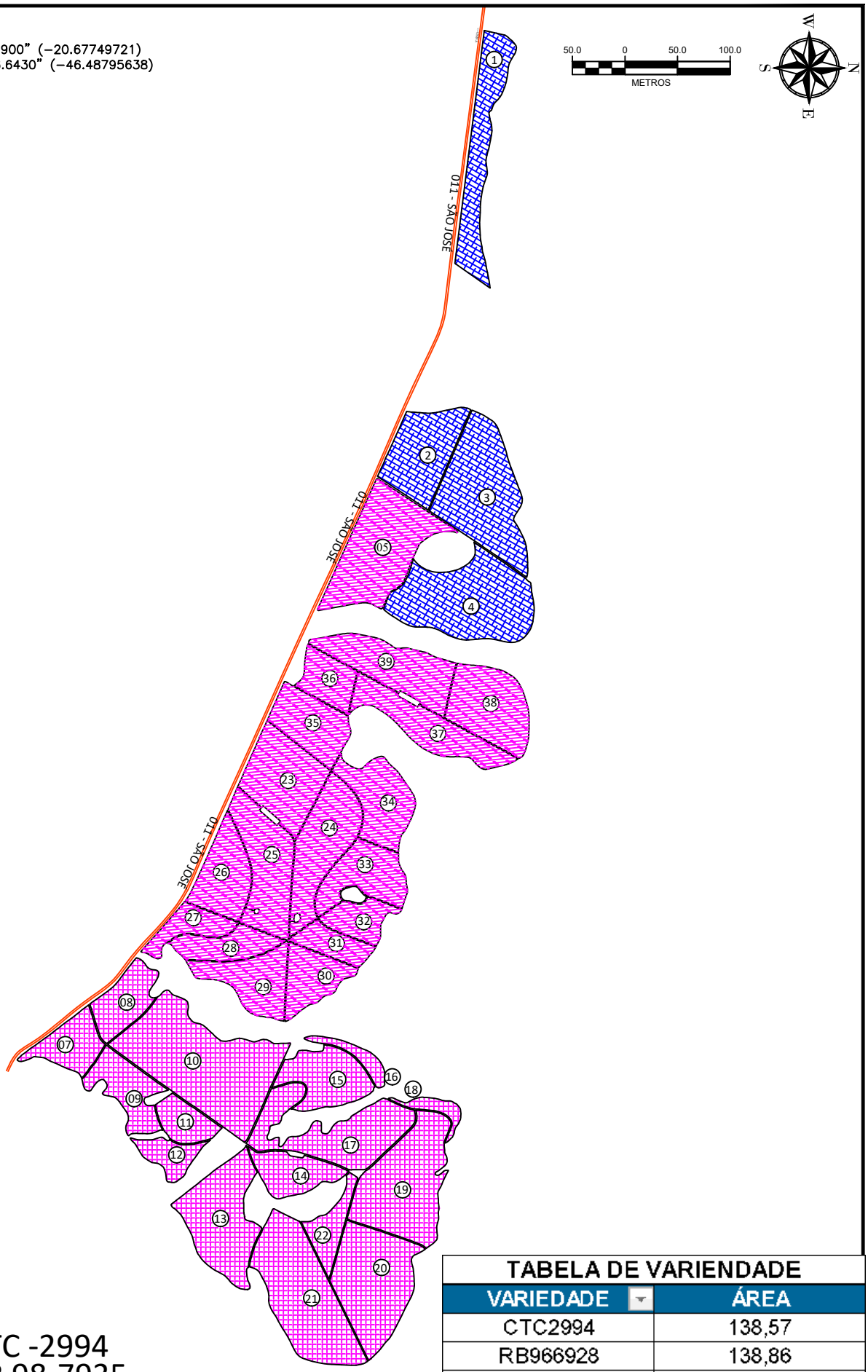

CTC -2994
RB 98-7935
RB 96-6928

TABELA DE VARIENDADE	
VARIEDADE	ÁREA
CTC2994	138,57
RB966928	138,86
RB987935	53,96
TOTAL	331,39

IPIRANGA AGROINDUSTRIAL

PROJETO: CADERNO DE MAPA 26'27	DATA: 05/03/2026	ESCALA: 1:5000	TOPÓGRAFO: CRISTIAN
FAZENDA: 012 - SÃO PEDRO	MUNICÍPIO: PASSOS MG		ÁREA (ha): 331,39
PROPRIETÁRIO: ITAIQUARA ALIMENTOS S.A	UNIDADE: IPIRANGA PASSOS		CÓDIGO: 012

Caderno de Mapas

Bloco	Talhao	Variedade	Estágio de Corte	Amb. Prod.	Data Plantio	Último Corte	Área (ha)	Estimativas Área (ha)	Finalid	Produt.	Prod. Total	Dist.	Esp.	Tipo Corte	Experimento
1 · REG 1			**12 · S.PEDRO**				**IPIRANGA AGROINDUSTRIAL S.A**								
1	1	RB987935	4C	BA	28/02/22	03/07/25	10,45	10,45	1-MO.	40,0	418,00	9	1,5	MEC.	
1	2	RB987935	4C	BA	28/12/21	10/07/25	9,84	9,84	1-MO.	58,0	570,72	9	1,5	MEC.	
1	3	RB987935	4C	BA	28/12/21	10/07/25	16,18	16,18	1-MO.	58,0	938,44	9	1,5	MEC.	
1	4	RB987935	5C	BA	28/12/21	10/07/25	17,49	17,49	1-MO.	58,0	1.014,42	9	1,5	MEC.	
1	5	CTC2994	1A	A	28/11/25		15,20	15,20	2-MU.	60,0	912,00	9	1,5	MEC.	
1	7	RB966928	4C	A	04/04/22	15/07/25	5,19	5,19	1-MO.	70,0	363,30	9	1,5	MEC.	
1	8	RB966928	4C	A	05/04/22	15/07/25	5,56	5,56	1-MO.	70,0	389,20	9	1,5	MEC.	
1	9	RB966928	4C	A	05/04/22	15/07/25	6,26	6,26	1-MO.	70,0	438,20	9	1,5	MEC.	
1	10	RB966928	4C	A	05/04/22	15/07/25	23,01	23,01	1-MO.	70,0	1.610,70	9	1,5	MEC.	
1	11	RB966928	4C	A	05/04/22	15/07/25	3,66	3,66	1-MO.	70,0	256,20	9	1,5	MEC.	
1	12	RB966928	4C	A	05/04/22	15/07/25	3,09	3,09	1-MO.	70,0	216,30	9	1,5	MEC.	
1	13	RB966928	4C	A	06/04/22	15/07/25	12,44	12,44	1-MO.	70,0	870,80	9	1,5	MEC.	
1	14	RB966928	4C	A	06/04/22	15/07/25	5,39	5,39	1-MO.	70,0	377,30	9	1,5	MEC.	
1	15	RB966928	4C	A	05/04/22	15/07/25	7,62	7,62	1-MO.	70,0	533,40	9	1,5	MEC.	
1	16	RB966928	4C	A	06/04/22	15/07/25	1,81	1,81	1-MO.	70,0	126,70	9	1,5	MEC.	
1	17	RB966928	4C	A	05/04/22	15/07/25	12,51	12,51	1-MO.	70,0	875,70	9	1,5	MEC.	
1	18	RB966928	4C	A	05/04/22	15/07/25	1,57	1,57	1-MO.	70,0	109,90	9	1,5	MEC.	
1	19	RB966928	4C	A	06/04/22	15/07/25	15,61	15,61	1-MO.	70,0	1.092,70	9	1,5	MEC.	
1	20	RB966928	4C	A	07/04/22	15/07/25	14,39	14,39	1-MO.	70,0	1.007,30	9	1,5	MEC.	
1	21	RB966928	4C	A	07/04/22	15/07/25	17,11	17,11	1-MO.	70,0	1.197,70	9	1,5	MEC.	
1	22	RB966928	4C	A	08/04/22	15/07/25	3,64	3,64	1-MO.	70,0	254,80	9	1,5	MEC.	
1	23	CTC2994	1C	A	23/02/25		10,44	10,44	1-MO.	138,0	1.440,72	9	1,5	MEC.	
1	24	CTC2994	1C	A	23/02/25		10,61	10,61	1-MO.	138,0	1.464,18	9	1,5	MEC.	
1	25	CTC2994	1C	A	22/02/25		10,53	10,53	1-MO.	138,0	1.453,14	9	1,5	MEC.	
1	26	CTC2994	1C	A	23/02/25		7,33	7,33	1-MO.	138,0	1.011,54	9	1,5	MEC.	
1	27	CTC2994	1C	A	22/02/25		3,79	3,79	1-MO.	138,0	523,02	9	1,5	MEC.	
1	28	CTC2994	1C	A	21/02/25		4,64	4,64	1-MO.	138,0	640,32	9	1,5	MEC.	
1	29	CTC2994	1C	A	22/02/25		7,18	7,18	1-MO.	100,0	718,00	9	1,5	MEC.	
1	30	CTC2994	1C	A	21/02/25		5,55	5,55	1-MO.	100,0	555,00	9	1,5	MEC.	
1	31	CTC2994	1C	A	21/02/25		3,47	3,47	1-MO.	100,0	347,00	9	1,5	MEC.	
1	32	CTC2994	1C	A	21/02/25		3,86	3,86	1-MO.	100,0	386,00	9	1,5	MEC.	
1	33	CTC2994	2C	A	21/02/25	17/11/25	7,38	7,38	2-MU.	70,0	516,60	9	1,5	MEC.	
1	34	CTC2994	2C	A	20/02/25	17/11/25	8,07	8,07	2-MU.	70,0	564,90	9	1,5	MEC.	
1	35	CTC2994	1C	A	20/02/25		7,17	7,17	2-MU.	70,0	501,90	9	1,5	MEC.	
1	36	CTC2994	1C	A	20/02/25		4,41	4,41	1-MO.	138,0	608,58	9	1,5	MEC.	
1	37	CTC2994	1C	A	19/02/25		8,80	8,80	1-MO.	138,0	1.214,40	9	1,5	MEC.	
1	38	CTC2994	1C	A	19/02/25		10,09	10,09	1-MO.	138,0	1.392,42	9	1,5	MEC.	
1	39	CTC2994	1C	A	20/02/25		10,05	10,05	1-MO.	138,0	1.386,90	9	1,5	MEC.	
Total/Média (1 / 12 · S.PEDRO)							331,39	331,39		85,4	28.298,40				

N: 7709394.436
E: 338537.9864
LAT: −20°42'30.2751" (−20.70840974)
LONG: −46°33'2.9832" (−46.55082866)

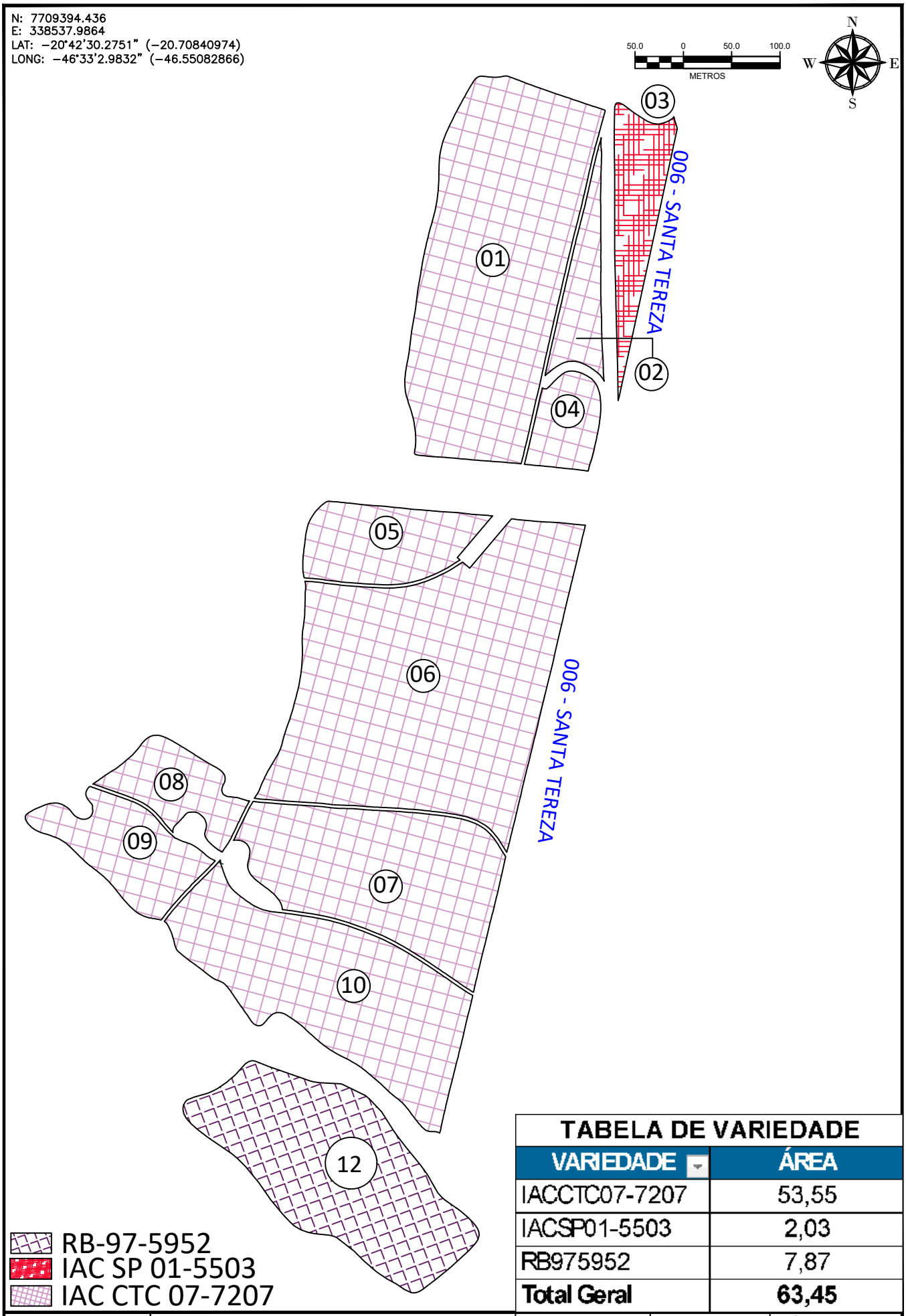

TABELA DE VARIEDADE

VARIEDADE	ÁREA
IACCTC07-7207	53,55
IACSP01-5503	2,03
RB975952	7,87
Total Geral	**63,45**

IPIRANGA AGROINDUSTRIAL

PROJETO: CADERNO DE MAPA 26'27	DATA: 30-12-2025	ESCALA: 1:5000	TOPÓGRAFO: CRISTIAN
FAZENDA: 013 - SÃO VICENTE	MUNICÍPIO: PASSOS MG		ÁREA (ha): 63,45
PROPRIETÁRIO: ITAIQUARA ALIMENTOS S.A	UNIDADE: IPIRANGA PASSOS		

Caderno de Mapas

Bloco	Talhao	Variedade	Estágio de Corte	Amb. Prod.	Data Plantio	Último Corte	Área (ha)	Estimativas Área (ha)	Finalid	Produt.	Prod. Total	Dist.	Esp.	Tipo Corte	Experimento
1 · REG 1			**13 · S.VICENTE**				**IPIRANGA AGROINDUSTRIAL S.A**								
1	1	IACCTC07-7207	1C	A	17/02/25	24/04/26	12,32	12,32	1-MO.	126,0	1.552,32	5,8	1,5	MEC.	
1	2	IACCTC07-7207	1C	A	18/02/25	24/04/26	1,51	1,51	1-MO.	126,0	190,26	5,8	1,5	MEC.	
1	3	IACSP01-5503	3C	A	26/03/23	05/09/25	2,03	2,03	1-MO.	80,0	162,40	5,8	1,5	MEC.	
1	4	IACCTC07-7207	1C	A	18/02/25	24/04/26	1,35	1,35	1-MO.	130,0	175,50	5,8	1,5	MEC.	
1	5	IACCTC07-7207	1C	A	16/02/25	24/04/26	2,80	2,80	1-MO.	130,0	364,00	5,8	1,5	MEC.	
1	6	IACCTC07-7207	1C	B	16/02/25	24/04/26	15,30	15,30	1-MO.	130,0	1.989,00	5,8	1,5	MEC.	
1	7	IACCTC07-7207	1C	B	16/02/25	24/04/26	7,31	7,31	1-MO.	130,0	950,30	5,8	1,5	MEC.	
1	8	IACCTC07-7207	1C	B	16/02/25	24/04/26	1,91	1,91	1-MO.	130,0	248,30	5,8	1,5	MEC.	
1	9	IACCTC07-7207	1C	BA	22/02/25	24/04/26	2,72	2,72	1-MO.	130,0	353,60	5,8	1,5	MEC.	
1	10	IACCTC07-7207	1C	BA	20/02/25	24/04/26	8,33	8,33	1-MO.	130,0	1.082,90	5,8	1,5	MEC.	
1	12	RB975952	4C	BA	29/12/21	05/11/25	7,87	7,87	1-MO.	45,0	354,15	5,8	1,5	MEC.	
Total/Média (1 / 13 · S.VICENTE)							63,45	63,45		117,0	7.422,73				

N: 7703833.171
E: 337718.3773
LAT: −20°45'30.8563" (−20.75857120)
LONG: −46°33'33.1606" (−46.55921128)

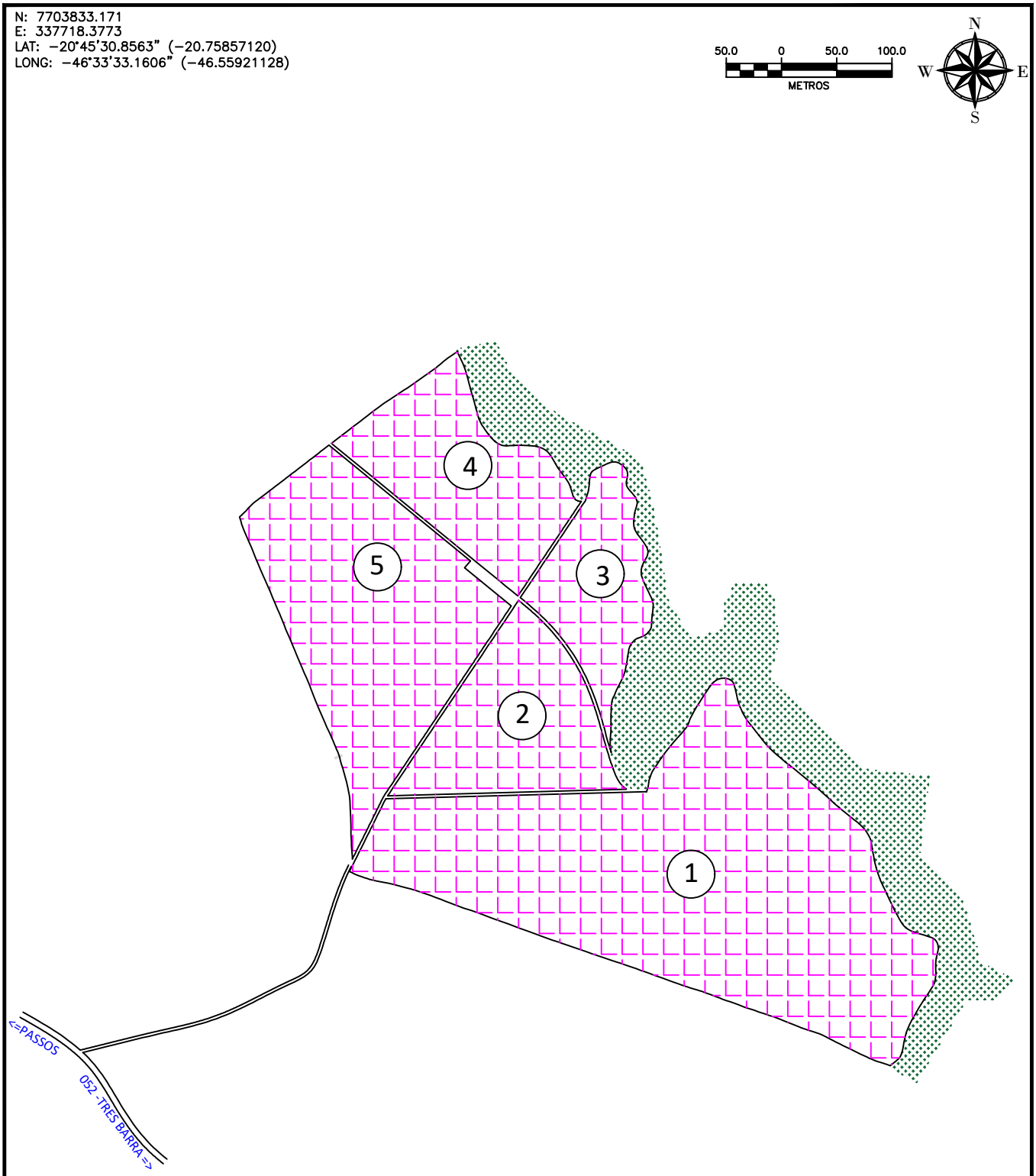

RB 96-6928

TABELA DE VARIEDADE

VARIEDADE	ÁREA
RB966928	63,16
Total Geral	**63,16**

IPIRANGA AGROINDUSTRIAL	PROJETO: CADERNO DE MAPA 26'27	DATA: 31/12/2025	ESCALA: 1:5000	TOPÓGRAFO: CRISTIAN
	FAZENDA: 014-SITIO NINFAS	MUNICÍPIO: PASSOS - MG		ÁREA (ha): 63,16
	PROPRIETÁRIO: ITAIQUARA ALIMENTOS	UNIDADE: IPIRANGA PASSOS		CÓDIGO: 014

Caderno de Mapas

Bloco	Talhao	Variedade	Estágio de Corte	Amb. Prod.	Data Plantio	Último Corte	Área (ha)	Estimativas Área (ha)	Finalid	Produt.	Prod. Total	Dist.	Esp.	Tipo Corte	Experimento
1 · REG 1			**14 · ST.NINFAS**				**IPIRANGA AGROINDUSTRIAL S.A**								
1	1	RB966928	4C	B	24/12/21	18/06/25	28,99	28,99	1-MO.	65,0	1.884,35	21	1,5	MEC.	
1	2	RB966928	4C	B	26/12/21	18/06/25	7,08	7,08	1-MO.	65,0	460,20	21	1,5	MEC.	
1	3	RB966928	4C	B	27/12/21	18/06/25	4,94	4,94	1-MO.	65,0	321,10	21	1,5	MEC.	
1	4	RB966928	4C	B	27/12/21	18/06/25	7,65	7,65	1-MO.	65,0	497,25	21	1,5	MEC.	
1	5	RB966928	4C	B	26/12/21	18/06/25	14,50	14,50	1-MO.	65,0	942,50	21	1,5	MEC.	
Total/Média (1 / 14 · ST.NINFAS)							63,16	63,16		65,0	4.105,40				

N: 7708607.341
E: 339122.3739
LAT: −20°42'56.0511" (−20.71556974)
LONG: −46°32'43.0464" (−46.54529068)

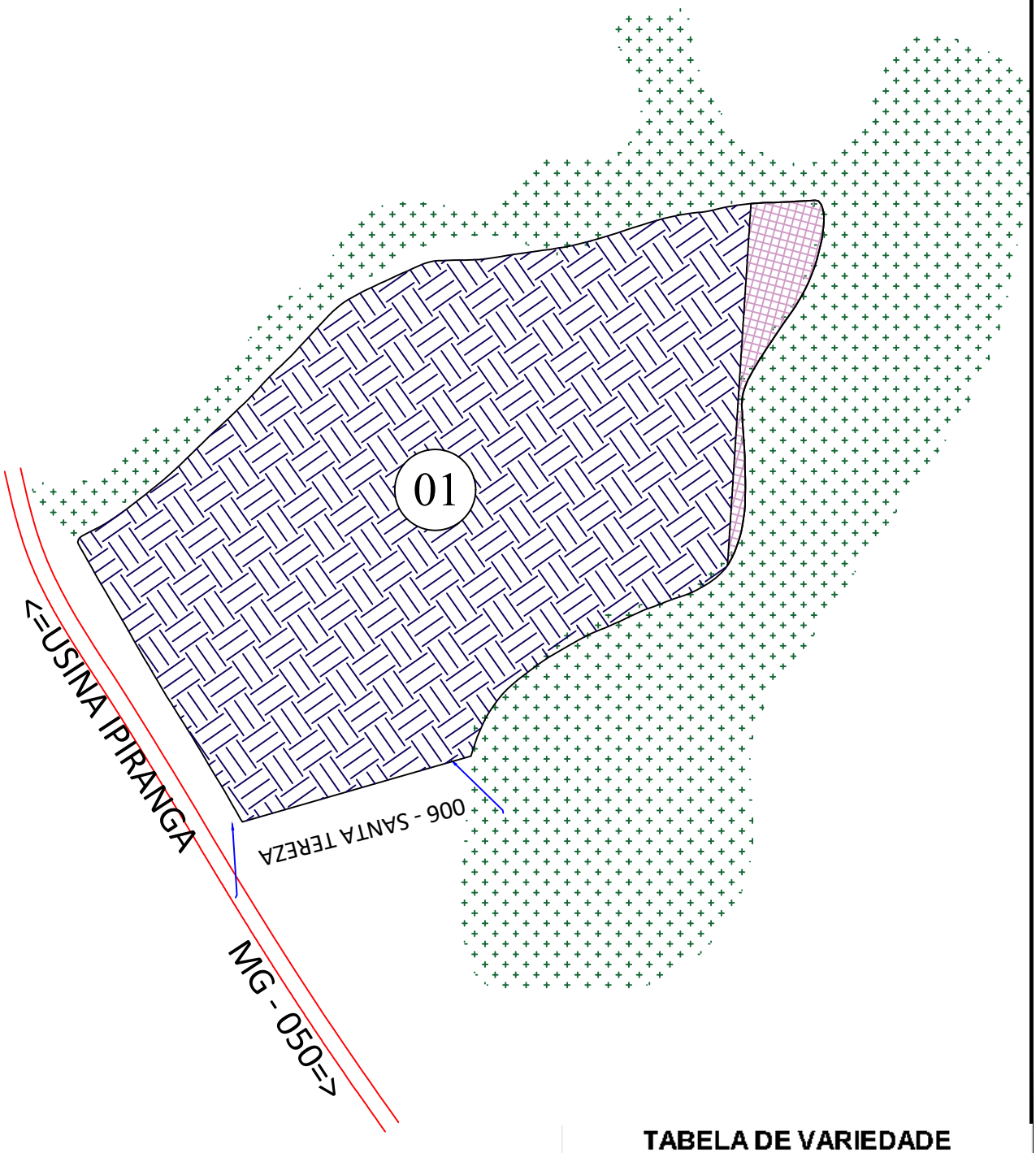

TABELA DE VARIEDADE

VARIEDADE	ÁREA
CTC9006	9,57
IACCTC077207	0,41
Total Geral	**9,98**

CTC - 9006
IAC CTC 07-7207

IPIRANGA AGROINDUSTRIAL

PROJETO: CADERNO DE MAPA 26'27	DATA: 05/01/2026	ESCALA: 1:5000	TOPÓGRAFO: CRISTIAN
FAZENDA: 015-SITIO SANTA TEREZA	MUNICÍPIO: PASSOS - MG		ÁREA (ha): 9,98
PROPRIETÁRIO: ITAIQUARA ALIMENTOS	UNIDADE: IPIRANGA PASSOS		CÓDIGO: 015

Caderno de Mapas

Bloco	Talhao	Variedade	Estágio de Corte	Amb. Prod.	Data Plantio	Último Corte	Área (ha)	Estimativas Área (ha)	Finalid	Produt.	Prod. Total	Dist.	Esp.	Tipo Corte	Experimento
1 · REG 1			**15 · ST.STA.TEREZA**				**IPIRANGA AGROINDUSTRIAL S.A**								
1	1	CTC9006	1C	A	19/02/25	24/04/26	9,57	1,94	1-MO.	100,0	194,00	6	1,5	MEC.	
1	1	CTC9006	1C	A	19/02/25	24/04/26	9,57	7,63	2-MU.	50,0	381,50	6	1,5	MEC.	
1	1	IACCTC07-7207	1C	A	19/02/25	24/04/26	0,41	0,33	2-MU.	50,0	16,50	6	1,5	MEC.	
1	1	IACCTC07-7207	1C	A	19/02/25	24/04/26	0,41	0,08	1-MO.	100,0	8,00	6	1,5	MEC.	
Total/Média (1 / 15 · ST.STA.TEREZA)							9,98	9,98		60,1	600,00				

N: 7708607.341
E: 339122.3739
LAT: −20°42'56.0511" (−20.71556974)
LONG: −46°32'43.0464" (−46.54529068)

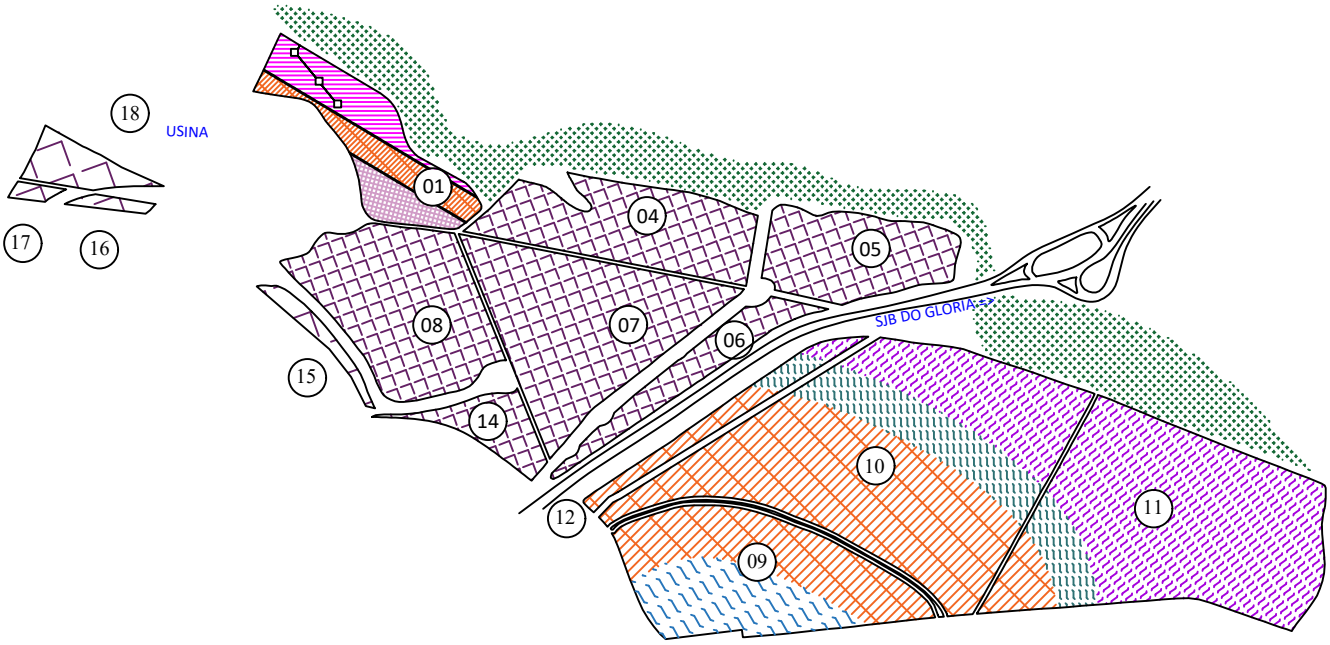

CTC - 9007
CTC - 9008
CTC - 9009
RB 12-7825
RB 97-5952
RB 92-8064
IAC CTC 07-7207

TABELA DE VARIEDADE

VARIEDADE	ÁREA
CTC9007	12,18
CTC9008	2,56
CTC9009	3,42
IACCTC07-7207	0,60
RB127825	13,91
RB928064	1,13
RB975952	21,90
Total Geral	**55,70**

IPIRANGA AGROINDUSTRIAL

PROJETO	DATA	ESCALA	TOPÓGRAFO
CADERNO DE MAPA 26'27	05/01/2026	1:5000	CRISTIAN

FAZENDA	MUNICÍPIO	ÁREA (ha)
016 - SOLEDADE	PASSOS - MG	55,70

PROPRIETÁRIO	UNIDADE	CÓDIGO
ITAIQUARA ALIMENTOS	IPIRANGA PASSOS	016

Caderno de Mapas

Bloco	Talhao	Variedade	Estágio de Corte	Amb. Prod.	Data Plantio	Último Corte	Área (ha)	Estimativas Área (ha)	Finalid	Produt.	Prod. Total	Dist.	Esp.	Tipo Corte	Experimento
1 · REG 1			**16 · SOLEDADE**				**IPIRANGA AGROINDUSTRIAL S.A**								
1	1	IACCTC07-7207	4C	A	10/11/22	13/06/25	0,60	0,60	1-MO.	78,0	46,80	3	1,5	MEC.	
1	1	RB127825	4C	A	10/11/22	13/06/25	1,41	1,41	1-MO.	78,0	109,98	3	1,5	MEC.	
1	1	RB928064	4C	A	10/11/22	13/06/25	1,13	1,13	1-MO.	78,0	88,14	3	1,5	MEC.	
1	4	RB975952	4C	A	19/04/22	13/06/25	3,86	3,86	1-MO.	78,0	301,08	3	1,5	MEC.	
1	5	RB975952	4C	A	21/04/22	13/06/25	2,97	2,97	1-MO.	78,0	231,66	3	1,5	MEC.	
1	6	RB975952	4C	A	19/04/22	13/06/25	1,51	1,51	1-MO.	78,0	117,78	3	1,5	MEC.	
1	7	RB975952	4C	A	19/04/22	13/06/25	5,86	5,86	1-MO.	78,0	457,08	3	1,5	MEC.	
1	8	RB975952	4C	A	19/04/22	13/06/25	5,02	5,02	1-MO.	78,0	391,56	3	1,5	MEC.	
1	9	CTC9008	2C	A	17/09/24	15/08/25	2,56	2,56	1-MO.	90,0	230,40	3	1,5	MEC.	
1	9	RB127825	2C	A	17/09/24	15/08/25	3,41	3,41	1-MO.	90,0	306,90	3	1,5	MEC.	
1	10	CTC9007	2C	A	25/09/24	15/08/25	3,30	3,30	1-MO.	90,0	297,00	3	1,5	MEC.	
1	10	CTC9009	2C	A	25/09/24	15/08/25	2,23	2,23	1-MO.	90,0	200,70	3	1,5	MEC.	
1	10	RB127825	2C	A	25/09/24	15/08/25	7,67	7,67	1-MO.	90,0	690,30	3	1,5	MEC.	
1	11	CTC9007	2C	A	24/09/24	15/08/25	8,72	8,72	1-MO.	90,0	784,80	3	1,5	MEC.	
1	11	CTC9009	2C	A	24/09/24	15/08/25	0,93	0,93	1-MO.	90,0	83,70	3	1,5	MEC.	
1	11	RB127825	2C	A	24/09/24	15/08/25	0,72	0,72	1-MO.	90,0	64,80	3	1,5	MEC.	
1	12	CTC9007	2C	A	23/09/24	15/08/25	0,16	0,16	1-MO.	90,0	14,40	3	1,5	MEC.	
1	12	CTC9009	2C	A	23/09/24	15/08/25	0,26	0,26	1-MO.	90,0	23,40	3	1,5	MEC.	
1	12	RB127825	2C	A	23/09/24	15/08/25	0,70	0,70	1-MO.	90,0	63,00	3	1,5	MEC.	
1	14	RB975952	4C	A	19/04/22	13/06/25	1,09	1,09	1-MO.	84,0	91,56	3	1,5	MEC.	
1	15	RB975952	3C	A	04/05/23	13/06/25	0,42	0,42	1-MO.	83,0	34,86	3	1,5	MEC.	
1	16	RB975952	3C	A	04/05/23	13/06/25	0,18	0,18	1-MO.	83,0	14,94	3	1,5	MEC.	
1	17	RB975952	3C	A	04/05/23	13/06/25	0,14	0,14	1-MO.	83,0	11,62	3	1,5	MEC.	
1	18	RB975952	3C	A	04/05/23	13/06/25	0,85	0,85	1-MO.	83,0	70,55	3	1,5	MEC.	
Total/Média (1 / 16 · SOLEDADE)							55,70	55,70		84,9	4.727,01				

N: 7713655.119
E: 338999.0508
LAT: −20°40'11.8712" (−20.66996421)
LONG: −46°32'45.6449" (−46.54601247)

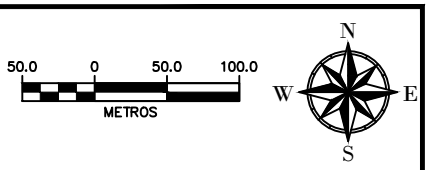

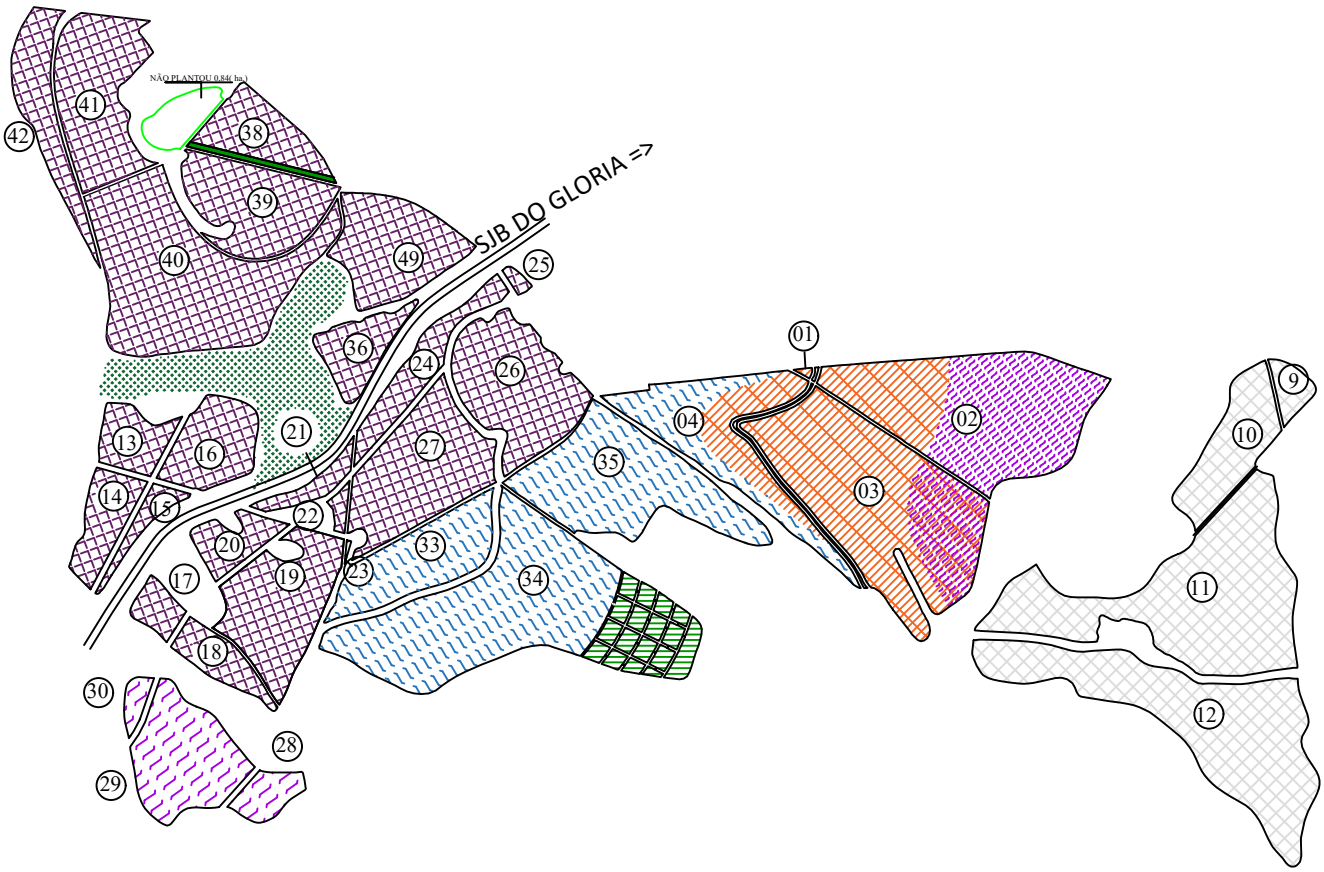

TABELA DE VARIEDADE	
VARIEDADE	ÁREA
CTC4	18,06
CTC9007	11,38
CTC9008	17,99
RB127825	9,92
RB975952	42,28
VIVEIRO	2,03
Total Geral	**101,66**

- CTC - 4
- VIVEIRO
- CTC - 9007
- CTC - 9008
- RB 12-7825
- RB-97-5952

IPIRANGA AGROINDUSTRIAL

PROJETO: CADERNO DE MAPA 26'27	DATA: 05/01/2026	ESCALA: 1:5000	TOPÓGRAFO: CRISTIAN
FAZENDA: 017 - SOLEDADE I	MUNICÍPIO: PASSOS - MG		ÁREA (ha): 101,66
PROPRIETÁRIO: ITAIQUARA ALIMENTOS	UNIDADE: IPIRANGA PASSOS		CÓDIGO: 017

Caderno de Mapas

Bloco	Talhao	Variedade	Estágio de Corte	Amb. Prod.	Data Plantio	Último Corte	Área (ha)	Estimativas Área (ha)	Finalid	Produt.	Prod. Total	Dist.	Esp.	Tipo Corte	Experimento
1 · REG 1			17 · SOLEDADE I				IPIRANGA AGROINDUSTRIAL S.A								
1	1	RB127825	2C	A	23/09/24	15/08/25	0,02	0,02	1-MO.	92,0	1,84	3	1,5	MEC.	
1	2	CTC9007	2C	A	23/09/24	15/08/25	5,07	5,07	1-MO.	92,0	466,44	3	1,5	MEC.	
1	2	RB127825	2C	A	23/09/24	15/08/25	2,21	2,21	1-MO.	92,0	203,32	3	1,5	MEC.	
1	3	CTC9007	2C	A	21/09/24	15/08/25	2,23	2,23	1-MO.	92,0	205,16	3	1,5	MEC.	
1	3	RB127825	2C	A	21/09/24	15/08/25	5,99	5,99	1-MO.	92,0	551,08	3	1,5	MEC.	
1	4	CTC9008	2C	A	18/09/24	15/08/25	2,35	2,35	1-MO.	92,0	216,20	3	1,5	MEC.	
1	4	RB127825	2C	A	18/09/24	15/08/25	1,70	1,70	1-MO.	92,0	156,40	3	1,5	MEC.	
1	9	CTC4	5C	A	08/11/21	22/07/25	0,49	0,49	1-MO.	70,0	34,30	3	1,5	MEC.	
1	10	CTC4	5C	A	08/11/21	22/07/25	2,25	2,25	1-MO.	70,0	157,50	3	1,5	MEC.	
1	11	CTC4	5C	A	06/11/21	22/07/25	8,01	8,01	1-MO.	70,0	560,70	3	1,5	MEC.	
1	12	CTC4	5C	A	07/11/21	22/07/25	7,31	7,31	1-MO.	70,0	511,70	3	1,5	MEC.	
1	13	RB975952	4C	A	20/04/22	13/06/25	1,09	1,09	1-MO.	78,0	85,02	3	1,5	MEC.	
1	14	RB975952	4C	A	20/04/22	13/06/25	1,28	1,28	1-MO.	78,0	99,84	3	1,5	MEC.	
1	15	RB975952	4C	A	20/04/22	13/06/25	0,50	0,50	1-MO.	78,0	39,00	3	1,5	MEC.	
1	16	RB975952	4C	A	20/04/22	13/06/25	1,89	1,89	1-MO.	78,0	147,42	3	1,5	MEC.	
1	17	RB975952	4C	A	20/04/22	13/06/25	0,55	0,55	1-MO.	78,0	42,90	3	1,5	MEC.	
1	18	RB975952	4C	A	20/04/22	13/06/25	0,98	0,98	1-MO.	78,0	76,44	3	1,5	MEC.	
1	19	RB975952	4C	A	20/04/22	13/06/25	3,41	3,41	1-MO.	78,0	265,98	3	1,5	MEC.	
1	20	RB975952	4C	A	20/04/22	13/06/25	0,94	0,94	1-MO.	78,0	73,32	3	1,5	MEC.	
1	21	RB975952	4C	A	20/04/22	13/06/25	0,46	0,46	1-MO.	78,0	35,88	3	1,5	MEC.	
1	22	RB975952	4C	A	20/04/22	13/06/25	0,16	0,16	1-MO.	78,0	12,48	3	1,5	MEC.	
1	23	RB975952	4C	A	19/04/22	13/06/25	0,01	0,01	1-MO.	78,0	0,78	3	1,5	MEC.	
1	24	RB975952	4C	A	20/04/22	13/06/25	1,44	1,44	1-MO.	78,0	112,32	3	1,5	MEC.	
1	25	RB975952	4C	A	20/04/22	13/06/25	0,07	0,07	1-MO.	78,0	5,46	3	1,5	MEC.	
1	26	RB975952	4C	A	20/04/22	13/06/25	3,81	3,81	1-MO.	78,0	297,18	3	1,5	MEC.	
1	27	RB975952	4C	A	20/04/22	13/06/25	3,98	3,98	1-MO.	78,0	310,44	3	1,5	MEC.	
1	28	CTC9007	3C	A	28/06/23	13/06/25	0,71	0,71	1-MO.	90,0	63,90	3	1,5	MEC.	
1	29	CTC9007	3C	A	29/06/23	13/06/25	3,07	3,07	1-MO.	90,0	276,30	3	1,5	MEC.	
1	30	CTC9007	3C	A	28/06/23	13/06/25	0,30	0,30	1-MO.	90,0	27,00	3	1,5	MEC.	
1	33	CTC9008	2C	A	26/06/24	13/06/25	2,74	2,74	1-MO.	100,0	274,00	3	1,5	MEC.	
1	34	CTC9008	2C	A	01/11/24	13/06/25	7,74	7,74	1-MO.	100,0	774,00	3	1,5	MEC.	
1	34	VIVEIRO	2C	A	01/11/24	13/06/25	1,80	1,80	1-MO.	100,0	180,00	3	1,5	MEC.	
1	35	CTC9008	2C	A	27/06/24	13/06/25	5,16	5,16	1-MO.	100,0	516,00	3	1,5	MEC.	
1	36	RB975952	4C	A	19/04/22	13/06/25	1,32	1,32	1-MO.	80,0	105,60	3	1,5	MEC.	
1	38	RB975952	3C	A	30/04/23	13/06/25	1,68	1,68	1-MO.	80,0	134,40	3	1,5	MEC.	
1	38	VIVEIRO	3C	A	30/04/23	13/06/25	0,23	0,23	1-MO.	80,0	18,40	3	1,5	MEC.	
1	39	RB975952	3C	A	30/04/23	13/06/25	3,02	3,02	1-MO.	83,0	250,66	3	1,5	MEC.	
1	40	RB975952	3C	A	30/04/23	13/06/25	7,26	7,26	1-MO.	83,0	602,58	3	1,5	MEC.	
1	41	RB975952	3C	A	30/04/23	13/06/25	3,51	3,51	1-MO.	83,0	291,33	3	1,5	MEC.	

Caderno de Mapas

Bloco	Talhao	Variedade	Estágio de Corte	Amb. Prod.	Data Plantio	Data Último Corte	Área (ha)	Estimativas Área (ha)	Estimativas Finalid	Estimativas Produt.	Prod. Total	Dist.	Esp.	Tipo Corte	Experimento
1	42	RB975952	3C	A	30/04/23	13/06/25	1,88	1,88	1-MO.	83,0	156,04	3	1,5	MEC.	
1	49	RB975952	4C	A	19/04/22	13/06/25	3,04	3,04	1-MO.	83,0	252,32	3	1,5	MEC.	
Total/Média (1 / 17 · SOLEDADE I)							101,66	101,66		84,5	8.591,63				

N: 7709394.436
E: 338537.9864
LAT: −20°42'30.2751" (−20.70840974)
LONG: −46°33'2.9832" (−46.55082866)

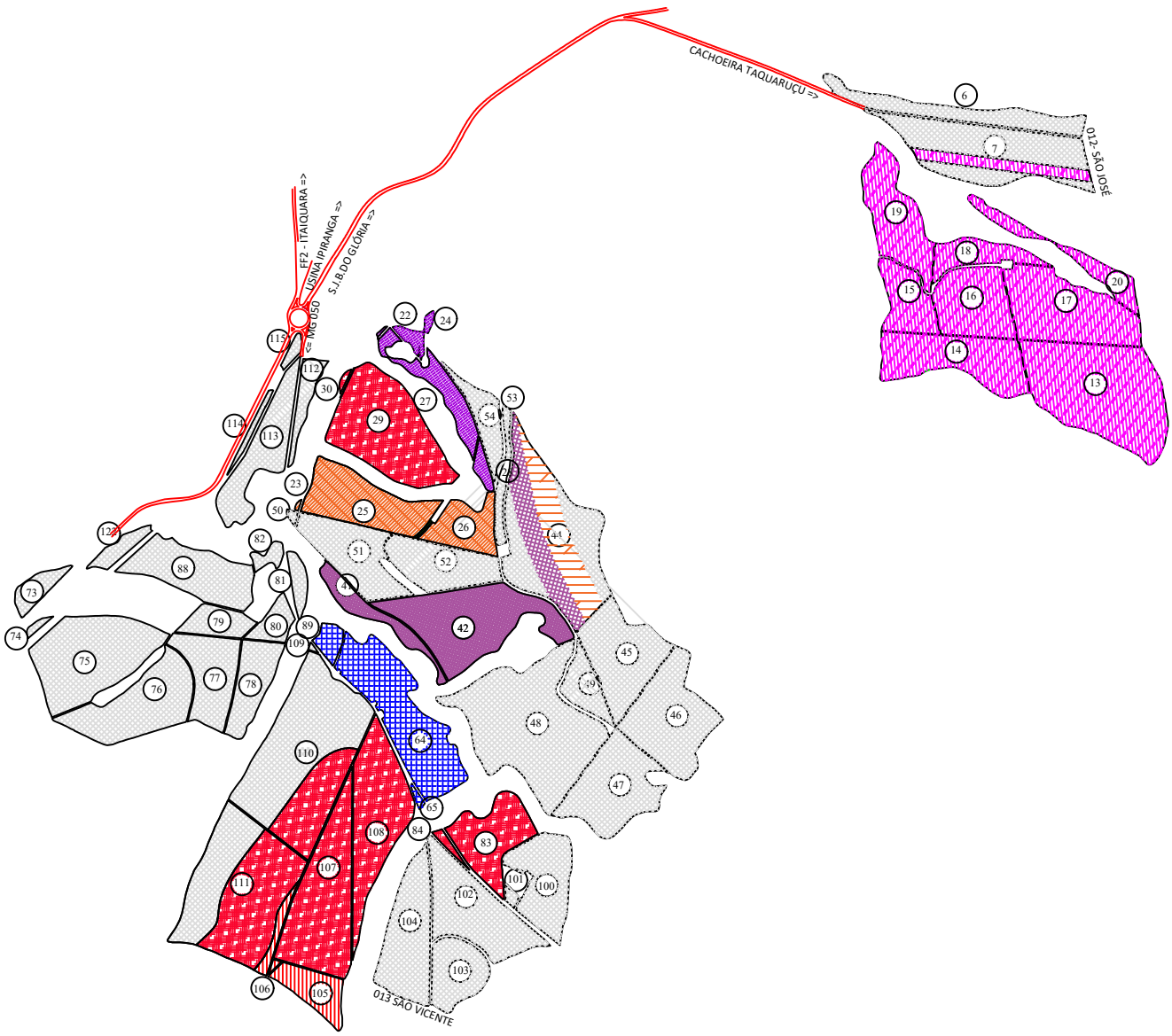

CTC - 2
CTC - 4
CTC - 9001
CTC - 9007
VIVEIRO
RB 12-7825
RB 85-5453
CT 02-2994
IAC CTC 07-8008
IAC SP 01-5503

TABELA DE VARIENDADE

VARIEDADE	ÁREA
CTC2	14,19
CTC2994	69,00
CTC4	218,93
CTC9001	6,66
CTC9007	6,26
IACCTC07-8008	23,28
IACSP01-5503	66,22
RB127825	13,30
RB855453	4,87
VIVEIRO	0,07
TOTAL	**422,78**

IPIRANGA AGROINDUSTRIAL

PROJETO	DATA	ESCALA	TOPÓGRAFO
CADERNO DE MAPA 26'27	21/01/2026	1:5000	CRISTIAN
FAZENDA	**MUNICÍPIO**		**ÁREA (ha)**
018 - SOLEDADE II	PASSOS MG		422,78
PROPRIETÁRIO	**UNIDADE**		**CÓDIGO**
ITAIQUARA ALIMENTOS S.A	IPIRANGA PASSOS		018

Caderno de Mapas

Bloco	Talhao	Variedade	Estágio de Corte	Amb. Prod.	Data Plantio	Último Corte	Área (ha)	Estimativas Área (ha)	Finalid	Produt.	Prod. Total	Dist.	Esp.	Tipo Corte	Experimento
1 · REG 1			**18 · SOLEDADE II**				**IPIRANGA AGROINDUSTRIAL S.A**								
1	6	CTC4	5C	A	17/11/21	22/07/25	6,13	6,13	1-MO.	75,0	459,75	5	1,5	MEC.	
1	7	CTC2994	5C	A	20/11/21	22/07/25	3,22	3,22	1-MO.	75,0	241,50	5	1,5	MEC.	
1	7	CTC4	5C	A	20/11/21	22/07/25	11,77	11,77	1-MO.	75,0	882,75	5	1,5	MEC.	
1	13	CTC2994	3C	A	15/03/23	20/06/25	18,98	18,98	1-MO.	92,0	1.746,16	5	1,5	MEC.	
1	14	CTC2994	3C	CB	17/03/23	20/06/25	9,84	9,84	1-MO.	92,0	905,28	5	1,5	MEC.	
1	15	CTC2994	3C	CB	04/04/23	20/06/25	4,63	4,63	1-MO.	92,0	425,96	5	1,5	MEC.	
1	16	CTC2994	3C	CB	03/04/23	20/06/25	7,62	7,62	1-MO.	92,0	701,04	5	1,5	MEC.	
1	17	CTC2994	3C	A	01/04/23	20/06/25	11,28	11,28	1-MO.	92,0	1.037,76	5	1,5	MEC.	
1	18	CTC2994	3C	A	08/04/23	20/06/25	2,26	2,26	1-MO.	92,0	207,92	5	1,5	MEC.	
1	19	CTC2994	3C	A	03/04/23	20/06/25	7,52	7,52	1-MO.	92,0	691,84	5	1,5	MEC.	
1	20	CTC2994	3C	A	04/04/23	20/06/25	3,65	3,65	1-MO.	92,0	335,80	5	1,5	MEC.	
1	21	CTC9007	2C	A	15/10/24	08/09/25	0,63	0,63	1-MO.	92,0	57,96	5	1,5	MEC.	
1	22	CTC9007	3C	A	06/04/23	08/09/25	0,70	0,70	1-MO.	92,0	64,40	5	1,5	MEC.	
1	23	RB127825	1IN	A	05/07/25	05/03/26	0,05	0,05	2-MU.	50,0	2,50	5	1,5	MEC.	
1	24	CTC9007	3C	A	06/04/23	08/09/25	0,22	0,22	1-MO.	90,0	19,80	5	1,5	MEC.	
1	25	RB127825	1IN	A	08/07/25		8,79	8,79	1-MO.	90,0	791,10	5	1,5	MEC.	
1	25	VIVEIRO	1IN	A	08/07/25		0,07	0,07	1-MO.	90,0	6,30	5	1,5	MEC.	
1	26	RB127825	1IN	A	07/07/25	05/03/26	4,46	4,46	2-MU.	50,0	223,00	5	1,5	MEC.	
1	27	CTC9007	3C	A	06/04/23	08/09/25	3,90	3,90	1-MO.	85,0	331,50	5	1,5	MEC.	
1	28	CTC9007	3C	A	06/04/23	08/09/25	0,81	0,81	1-MO.	85,0	68,85	5	1,5	MEC.	
1	29	IACSP01-5503	3C	A	18/09/23	08/09/25	14,43	14,43	1-MO.	85,0	1.226,55	5	1,5	MEC.	
1	30	IACSP01-5503	3C	A	18/09/23	08/09/25	0,16	0,16	1-MO.	85,0	13,60	5	1,5	MEC.	
1	41	IACCTC07-8008	4C	A	07/07/22	08/09/25	3,28	3,28	1-MO.	65,0	213,20	5	1,5	MEC.	
1	42	IACCTC07-8008	4C	BA	08/07/22	08/09/25	13,93	13,93	1-MO.	65,0	905,45	5	1,5	MEC.	
1	44	CTC4	5C	A	08/07/21	08/09/25	6,78	6,78	1-MO.	73,0	494,94	5	1,5	MEC.	
1	44	CTC9001	5C	A	08/07/21	08/09/25	6,66	6,66	1-MO.	73,0	486,18	5	1,5	MEC.	
1	44	IACCTC07-8008	5C	A	08/07/21	08/09/25	6,07	6,07	1-MO.	73,0	443,11	5	1,5	MEC.	
1	45	CTC4	5C	B	16/07/21	08/09/25	9,34	9,34	1-MO.	73,0	681,82	5	1,5	MEC.	
1	46	CTC4	5C	B	25/06/21	08/09/25	10,93	10,93	1-MO.	73,0	797,89	5	1,5	MEC.	
1	47	CTC4	5C	A	28/06/21	08/09/25	10,01	10,01	1-MO.	73,0	730,73	5	1,5	MEC.	
1	48	CTC4	5C	A	19/07/21	08/09/25	21,39	21,39	1-MO.	73,0	1.561,47	5	1,5	MEC.	
1	49	CTC4	5C	BA	16/07/21	08/09/25	2,93	2,93	1-MO.	73,0	213,89	5	1,5	MEC.	
1	50	CTC4	5C	A	07/07/21	08/09/25	0,16	0,16	1-MO.	73,0	11,68	5	1,5	MEC.	
1	51	CTC4	5C	A	25/06/21	08/09/25	7,60	7,60	1-MO.	73,0	554,80	5	1,5	MEC.	
1	52	CTC4	5C	A	03/07/21	08/09/25	6,65	6,65	1-MO.	73,0	485,45	5	1,5	MEC.	
1	53	CTC4	5C	A	13/07/21	08/09/25	1,48	1,48	1-MO.	73,0	108,04	5	1,5	MEC.	
1	54	CTC4	5C	A	13/07/21	08/09/25	3,07	3,07	1-MO.	73,0	224,11	5	1,5	MEC.	
1	64	CTC2	3C	BA	07/09/23	23/04/26	12,97	12,97	2-MU.	60,0	778,20	5	1,5	MEC.	
1	65	CTC2	3C	BA	08/09/23	23/04/26	0,14	0,14	2-MU.	60,0	8,40	5	1,5	MEC.	

Caderno de Mapas

Bloco	Talhao	Variedade	Estágio de Corte	Amb. Prod.	Data Plantio	Data Último Corte	Área (ha)	Estimativas Área (ha)	Estimativas Finalid	Estimativas Produt.	Prod. Total	Dist.	Esp.	Tipo Corte	Experimento
1	73	CTC4	4C	A	08/03/22	27/08/25	1,87	1,87	1-MO.	77,0	143,99	5	1,5	MEC.	
1	74	CTC4	4C	B	09/03/22	27/08/25	0,24	0,24	1-MO.	77,0	18,48	5	1,5	MEC.	
1	75	CTC4	4C	B	09/03/22	27/08/25	13,47	13,47	1-MO.	77,0	1.037,19	5	1,5	MEC.	
1	76	CTC4	4C	CB	09/03/22	27/08/25	10,10	10,10	1-MO.	77,0	777,70	5	1,5	MEC.	
1	77	CTC4	4C	B	09/03/22	27/08/25	6,66	6,66	1-MO.	77,0	512,82	5	1,5	MEC.	
1	78	CTC4	4C	CB	08/03/22	27/08/25	4,84	4,84	1-MO.	77,0	372,68	5	1,5	MEC.	
1	79	CTC4	4C	A	08/03/22	27/08/25	2,77	2,77	1-MO.	77,0	213,29	5	1,5	MEC.	
1	80	CTC4	4C	A	09/03/22	27/08/25	1,98	1,98	1-MO.	77,0	152,46	5	1,5	MEC.	
1	81	CTC4	4C	A	09/03/22	27/08/25	1,26	1,26	1-MO.	77,0	97,02	5	1,5	MEC.	
1	82	CTC4	4C	A	09/03/22	27/08/25	0,83	0,83	1-MO.	77,0	63,91	5	1,5	MEC.	
1	83	IACSP01-5503	3C	B	11/03/23	29/08/25	7,12	7,12	1-MO.	77,0	548,24	5	1,5	MEC.	
1	84	IACSP01-5503	3C	B	11/03/23	29/08/25	0,41	0,41	1-MO.	77,0	31,57	5	1,5	MEC.	
1	88	CTC4	4C	A	09/03/22	27/08/25	8,54	8,54	1-MO.	77,0	657,58	5	1,5	MEC.	
1	89	CTC2	4C	BA	31/10/22	16/04/26	1,08	1,08	2-MU.	50,0	54,00	5	1,5	MEC.	
1	100	CTC4	4C	B	10/04/22	29/08/25	7,33	7,33	1-MO.	55,0	403,15	5	1,5	MEC.	
1	101	CTC4	4C	B	10/04/22	29/08/25	0,29	0,29	1-MO.	55,0	15,95	5	1,5	MEC.	
1	102	CTC4	4C	B	09/04/22	29/08/25	10,19	10,19	1-MO.	70,0	713,30	5	1,5	MEC.	
1	103	CTC4	4C	A	08/04/22	29/08/25	5,03	5,03	1-MO.	70,0	352,10	5	1,5	MEC.	
1	104	CTC4	4C	B	08/04/22	05/05/26	8,89	8,89	1-MO.	70,0	622,30	5	1,5	MEC.	
1	105	RB855453	4C	BA	08/03/22	29/08/25	3,69	3,69	1-MO.	70,0	258,30	5	1,5	MEC.	
1	106	RB855453	4C	BA	08/03/22	29/08/25	0,10	0,10	1-MO.	70,0	7,00	5	1,5	MEC.	
1	107	IACSP01-5503	4C	BA	08/03/22	29/08/25	13,83	13,83	1-MO.	70,0	968,10	5	1,5	MEC.	
1	108	IACSP01-5503	4C	BA	08/03/22	29/08/25	11,74	11,74	1-MO.	70,0	821,80	5	1,5	MEC.	
1	109	CTC4	4C	BA	07/03/22	29/08/25	0,06	0,06	1-MO.	70,0	4,20	5	1,5	MEC.	
1	110	CTC4	4C	BA	07/03/22	29/08/25	17,06	17,06	1-MO.	70,0	1.194,20	5	1,5	MEC.	
1	110	IACSP01-5503	4C	BA	07/03/22	29/08/25	6,69	6,69	1-MO.	70,0	468,30	5	1,5	MEC.	
1	111	CTC4	4C	BA	07/03/22	29/08/25	8,28	8,28	1-MO.	70,0	579,60	5	1,5	MEC.	
1	111	IACSP01-5503	4C	BA	07/03/22	29/08/25	11,84	11,84	1-MO.	70,0	828,80	5	1,5	MEC.	
1	111	RB855453	4C	BA	07/03/22	29/08/25	1,08	1,08	1-MO.	70,0	75,60	5	1,5	MEC.	
1	112	CTC4	4C	A	09/03/22	08/09/25	1,84	1,84	1-MO.	70,0	128,80	5	1,5	MEC.	
1	113	CTC4	4C	A	10/03/22	08/09/25	7,16	7,16	1-MO.	70,0	501,20	5	1,5	MEC.	
1	114	CTC4	4C	A	10/03/22	08/09/25	0,28	0,28	1-MO.	70,0	19,60	5	1,5	MEC.	
1	115	CTC4	4C	A	10/03/22	08/09/25	0,35	0,35	1-MO.	70,0	24,50	5	1,5	MEC.	
1	122	CTC4	4C	A	09/03/22	27/08/25	1,37	1,37	1-MO.	70,0	95,90	5	1,5	MEC.	
Total/Média (1 / 18 · SOLEDADE II)							422,78	422,78		75,5	31.904,31				

N: 7708979.482
E: 347783.4128
LAT: −20°42'46.5647" (−20.71293464)
LONG: −46°27'43.5863" (−46.46210731)

TABELA DE VARIEDADE

VARIEDADE	ÁREA
CTC2	2,46
CTC4	37,56
CTC9006	328,56
CTC9007	46,73
CTC9011	5,44
IACCTC07-7207	95,34
RB075253	1,74
RB966928	68,01
RB987935	20,41
VIVEIRO	7,54
Total Geral	**613,79**

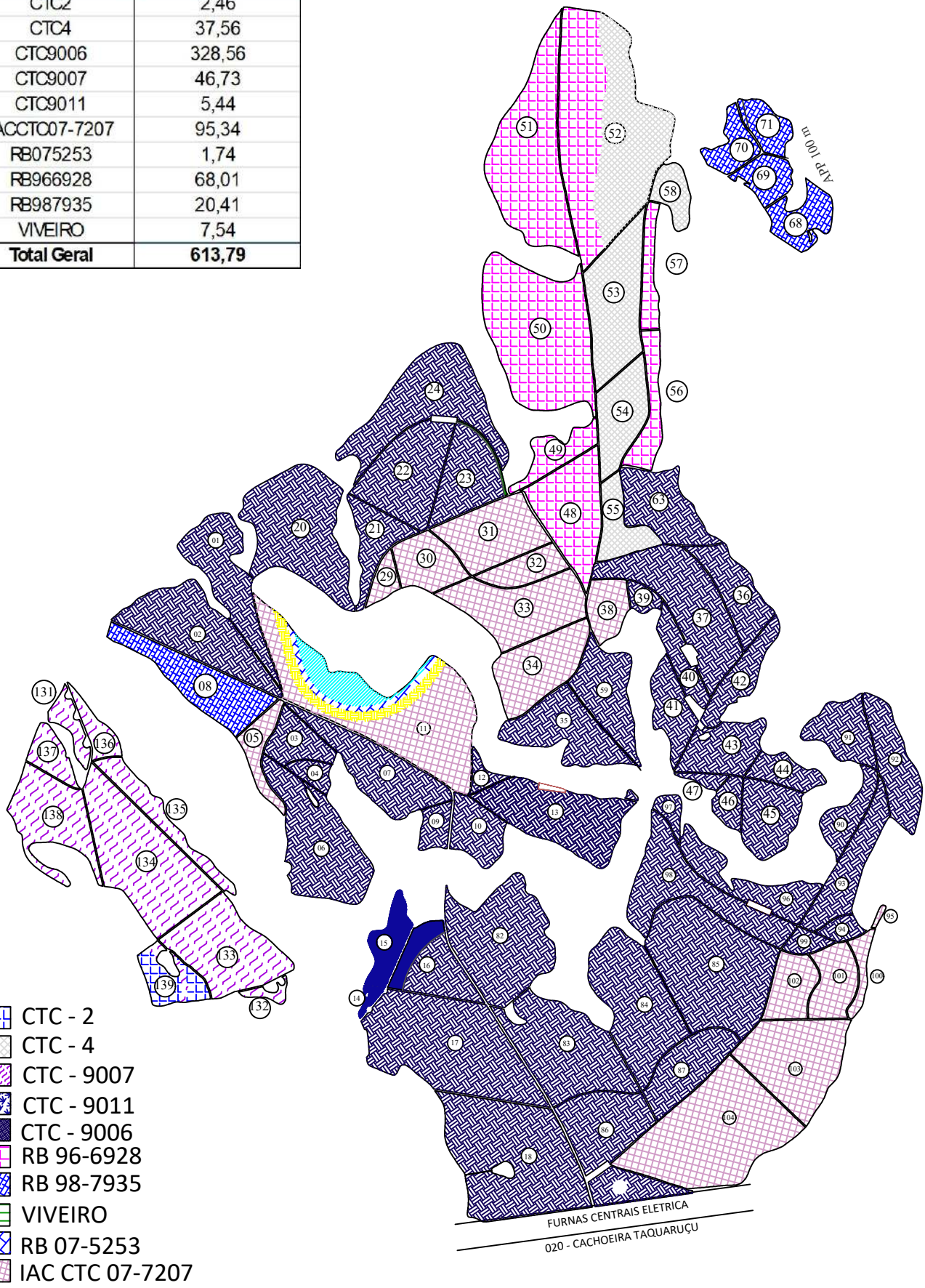

IPIRANGA AGROINDUSTRIAL	PROJETO: CADERNO DE MAPA 26'27	DATA: 21/05/2026	ESCALA: 1:5000	TOPÓGRAFO: CRISTIAN
	FAZENDA: 019 - TAQUARUSSU	MUNICÍPIO: PASSOS - MG		ÁREA (ha): 613,79
	PROPRIETÁRIO: AGROPRCUARIA VALE DO RIO GRANDE	UNIDADE: IPIRANGA PASSOS - MG		CÓDIGO: 019

Caderno de Mapas

Bloco	Talhao	Variedade	Estágio de Corte	Amb. Prod.	Data Plantio	Data Último Corte	Área (ha)	Estimativas Área (ha)	Estimativas Finalid	Estimativas Produt.	Prod. Total	Dist.	Esp.	Tipo Corte	Experimento
1 · REG 1			**19 · TAQUARUÇU**				**IPIRANGA AGROINDUSTRIAL S.A**								
1	1	CTC9006	FORM	A	26/03/26		7,86	0,00	.		0,00	12	1,5	N/D	
1	2	CTC9006	FORM	A	18/03/26		11,02	0,00	.		0,00	12	1,5	N/D	
1	3	CTC9006	FORM	A	21/03/26		3,34	0,00	.		0,00	12	1,5	N/D	
1	4	CTC9006	FORM	A	21/03/26		1,29	0,00	.		0,00	12	1,5	N/D	
1	5	IACCTC07-7207	3C	B	09/12/23	26/09/25	2,72	2,72	1-MO.	68,0	184,96	12	1,5	MEC.	
1	6	CTC9006	FORM	A	24/03/26		11,83	0,00	.		0,00	12	1,5	N/D	
1	7	CTC9006	FORM	A	19/03/26		8,56	0,00	.		0,00	12	1,5	N/D	
1	8	RB987935	3C	B	23/11/22	26/09/25	8,15	8,15	1-MO.	60,0	489,00	12	1,5	MEC.	
1	9	CTC9006	FORM	A	18/03/26		1,76	0,00	.		0,00	12	1,5	N/D	
1	10	CTC9006	FORM	A	18/03/26		4,07	0,00	.		0,00	12	1,5	N/D	
1	11	IACCTC07-7207	1C	A	17/02/25	15/05/26	14,21	12,08	1-MO.	100,0	1.208,00	12	1,5	MEC.	
1	11	IACCTC07-7207	1C	A	17/02/25	15/05/26	14,21	2,13	2-MU.	70,0	149,10	12	1,5	MEC.	
1	11	RB075253	1C	A	17/02/25	15/05/26	1,74	0,26	2-MU.	70,0	18,20	12	1,5	MEC.	
1	11	RB075253	1C	A	17/02/25	15/05/26	1,74	1,48	1-MO.	100,0	148,00	12	1,5	MEC.	
1	11	VIVEIRO	1C	A	17/02/25	15/05/26	7,29	6,20	1-MO.	100,0	620,00	12	1,5	MEC.	
1	11	VIVEIRO	1C	A	17/02/25	15/05/26	7,29	1,09	2-MU.	70,0	76,30	12	1,5	MEC.	
1	12	CTC9006	FORM	DC	06/03/26		0,96	0,00	.		0,00	12	1,5	N/D	
1	13	CTC9006	FORM	DC	06/03/26		10,90	0,00	.		0,00	12	1,5	N/D	
1	14	CTC9011	FORM	A	03/03/26		0,44	0,00	.		0,00	12	1,5	N/D	
1	15	CTC9011	FORM	A	04/03/26		3,12	0,00	.		0,00	12	1,5	N/D	
1	16	CTC9006	FORM	B	07/03/26		4,24	0,00	.		0,00	12	1,5	N/D	
1	16	CTC9011	FORM	B	07/03/26		1,88	0,00	.		0,00	12	1,5	N/D	
1	17	CTC9006	FORM	A	06/03/26		19,16	0,00	.		0,00	12	1,5	N/D	
1	18	CTC9006	FORM	A	28/03/26		19,66	0,00	.		0,00	12	1,5	N/D	
1	19	CTC9006	FORM	B	07/03/26		3,35	0,00	.		0,00	12	1,5	N/D	
1	20	CTC9006	2C	A	14/11/23	15/05/26	14,37	14,37	1-MO.	105,0	1.508,85	12	1,5	MEC.	
1	21	CTC9006	2C	A	02/12/23	15/05/26	4,02	4,02	1-MO.	105,0	422,10	12	1,5	MEC.	
1	22	CTC9006	2C	A	18/11/23	15/05/26	9,49	9,49	1-MO.	105,0	996,45	12	1,5	MEC.	
1	23	CTC9006	2C	A	21/11/23	15/05/26	6,43	6,43	1-MO.	105,0	675,15	12	1,5	MEC.	
1	23	VIVEIRO	2C	A	21/11/23	15/05/26	0,25	0,25	1-MO.	105,0	26,25	12	1,5	MEC.	
1	24	CTC9006	2C	A	17/11/23	15/05/26	12,43	12,43	1-MO.	105,0	1.305,15	12	1,5	MEC.	
1	29	IACCTC07-7207	2C	B	16/11/23	15/05/26	1,44	1,44	1-MO.	100,0	144,00	12	1,5	MEC.	
1	30	IACCTC07-7207	2C	B	16/11/23	15/05/26	4,53	4,53	1-MO.	100,0	453,00	12	1,5	MEC.	
1	31	IACCTC07-7207	2C	A	25/11/23	15/05/26	7,92	7,92	1-MO.	100,0	792,00	12	1,5	MEC.	
1	32	IACCTC07-7207	2C	A	18/11/23	15/05/26	3,10	3,10	1-MO.	100,0	310,00	12	1,5	MEC.	
1	33	IACCTC07-7207	2C	B	17/11/23	15/05/26	9,88	9,88	1-MO.	100,0	988,00	12	1,5	MEC.	
1	34	IACCTC07-7207	2C	B	25/11/23	15/05/26	7,71	7,71	1-MO.	100,0	771,00	12	1,5	MEC.	
1	35	CTC9006	FORM	B	15/04/26		7,74	0,00	.		0,00	12	1,5	N/D	
1	36	CTC9006	2C	C	04/12/23	13/05/26	5,16	5,16	1-MO.	105,0	541,80	12	1,5	MEC.	

Caderno de Mapas

Bloco	Talhao	Variedade	Estágio de Corte	Amb. Prod.	Data Plantio	Data Último Corte	Área (ha)	Estimativas Área (ha)	Estimativas Finalid	Estimativas Produt.	Prod. Total	Dist.	Esp.	Tipo Corte	Experimento
1	37	CTC9006	2C	C	05/12/23	13/05/26	11,99	11,99	1-MO.	105,0	1.258,95	12	1,5	MEC.	
1	38	IACCTC07-7207	2C	C	04/12/23	15/05/26	3,17	2,24	2-MU.	60,0	134,40	12	1,5	MEC.	
1	38	IACCTC07-7207	2C	C	04/12/23	15/05/26	3,17	0,93	1-MO.	80,0	74,40	12	1,5	MEC.	
1	39	CTC9006	2C	C	06/12/23	13/05/26	1,07	1,07	1-MO.	83,0	88,81	12	1,5	MEC.	
1	40	CTC9006	2C	C	07/12/23	13/05/26	2,67	2,67	1-MO.	83,0	221,61	12	1,5	MEC.	
1	41	CTC9006	3C	DC	08/12/23	13/05/26	3,99	3,99	1-MO.	83,0	331,17	12	1,5	MEC.	
1	42	CTC9006	3C	C	07/12/23	13/05/26	3,71	3,71	1-MO.	83,0	307,93	12	1,5	MEC.	
1	43	CTC9006	3C	DC	08/12/23	13/05/26	5,10	5,10	1-MO.	83,0	423,30	12	1,5	MEC.	
1	44	CTC9006	3C	A	11/12/23	13/05/26	2,63	1,63	1-MO.	83,0	135,29	12	1,5	MEC.	
1	44	CTC9006	3C	A	11/12/23	13/05/26	2,63	1,00	2-MU.	60,0	60,00	12	1,5	MEC.	
1	45	CTC9006	3C	A	08/12/23	13/05/26	5,47	5,47	1-MO.	83,0	454,01	12	1,5	MEC.	
1	46	CTC9006	3C	DC	08/12/23	13/05/26	1,75	1,75	1-MO.	83,0	145,25	12	1,5	MEC.	
1	47	CTC9006	3C	DC	08/12/23	13/05/26	0,69	0,69	1-MO.	83,0	57,27	12	1,5	MEC.	
1	48	RB966928	5C	A	23/04/21	26/09/25	8,96	8,96	1-MO.	55,0	492,80	12	1,5	MEC.	
1	49	RB966928	5C	A	23/04/21	26/09/25	3,22	3,22	1-MO.	55,0	177,10	12	1,5	MEC.	
1	50	RB966928	5C	A	26/04/21	26/09/25	19,45	19,45	1-MO.	55,0	1.069,75	12	1,5	MEC.	
1	51	RB966928	5C	A	25/04/21	26/09/25	16,74	16,74	1-MO.	55,0	920,70	12	1,5	MEC.	
1	52	CTC4	5C	A	23/04/21	26/09/25	14,62	14,62	1-MO.	55,0	804,10	12	1,5	MEC.	
1	52	RB966928	5C	A	23/04/21	26/09/25	13,65	13,65	1-MO.	55,0	750,75	12	1,5	MEC.	
1	53	CTC4	5C	A	22/04/21	26/09/25	10,32	10,32	1-MO.	55,0	567,60	12	1,5	MEC.	
1	54	CTC4	5C	A	22/04/21	26/09/25	6,11	6,11	1-MO.	55,0	336,05	12	1,5	MEC.	
1	55	CTC4	5C	A	22/04/21	26/09/25	3,94	3,94	1-MO.	55,0	216,70	12	1,5	MEC.	
1	56	RB966928	5C	B	26/04/21	26/09/25	3,52	3,52	1-MO.	55,0	193,60	12	1,5	MEC.	
1	57	RB966928	5C	BA	26/04/21	26/09/25	2,47	2,47	1-MO.	55,0	135,85	12	1,5	MEC.	
1	58	CTC4	5C	BA	23/04/21	26/09/25	2,57	2,57	1-MO.	55,0	141,35	12	1,5	MEC.	
1	59	CTC9006	FORM	B	31/03/26		6,38	0,00	.		0,00	12	1,5	N/D	
1	63	CTC9006	3C	B	03/12/23	13/05/26	6,86	6,86	1-MO.	73,0	500,78	12	1,5	MEC.	
1	68	RB987935	3C	C	25/11/22	26/09/25	3,84	3,84	1-MO.	73,0	280,32	12	1,5	MEC.	
1	69	RB987935	3C	A	25/11/22	26/09/25	2,82	2,82	1-MO.	73,0	205,86	12	1,5	MEC.	
1	70	RB987935	4C	C	24/11/22	26/09/25	2,83	2,83	1-MO.	73,0	206,59	12	1,5	MEC.	
1	71	RB987935	3C	C	24/11/22	26/09/25	2,77	2,77	1-MO.	73,0	202,21	12	1,5	MEC.	
1	82	CTC9006	FORM	C	27/03/26		13,58	0,00	.		0,00	12	1,5	N/D	
1	83	CTC9006	FORM	A	30/03/26		12,86	0,00	.		0,00	12	1,5	N/D	
1	84	CTC9006	FORM	C	30/03/26		12,50	0,00	.		0,00	12	1,5	N/D	
1	85	CTC9006	FORM	A	26/03/26		17,86	0,00	.		0,00	12	1,5	N/D	
1	86	CTC9006	FORM	A	08/03/26		7,60	0,00	.		0,00	12	1,5	N/D	
1	87	CTC9006	FORM	A	28/03/26		6,05	0,00	.		0,00	12	1,5	N/D	
1	90	CTC9006	1C	B	28/03/25	17/02/26	3,01	3,01	2-MU.	70,0	210,70	12	1,5	MEC.	
1	91	CTC9006	1C	B	25/03/25	17/02/26	4,63	4,63	2-MU.	70,0	324,10	12	1,5	MEC.	
1	92	CTC9006	1C	B	26/03/25	17/02/26	5,85	5,85	2-MU.	70,0	409,50	12	1,5	MEC.	
1	93	CTC9006	1C	C	25/03/25	17/02/26	5,74	5,74	2-MU.	70,0	401,80	12	1,5	MEC.	

Caderno de Mapas

Bloco	Talhao	Variedade	Estágio de Corte	Amb. Prod.	Data Plantio	Data Último Corte	Área (ha)	Estimativas Área (ha)	Estimativas Finalid	Estimativas Produt.	Prod. Total	Dist.	Esp.	Tipo Corte	Experimento
1	94	CTC9006	1C	C	26/03/25	10/03/26	1,14	1,14	2-MU.	70,0	79,80	12	1,5	MEC.	
1	95	IACCTC07-7207	1C	C	25/03/25	08/05/26	0,17	0,17	1-MO.	110,0	18,70	12	1,5	MEC.	
1	96	CTC9006	1C	A	24/03/25	17/02/26	5,60	5,60	2-MU.	70,0	392,00	12	1,5	MEC.	
1	97	CTC9006	1C	A	24/03/25	17/02/26	1,06	1,06	2-MU.	70,0	74,20	12	1,5	MEC.	
1	98	CTC9006	1C	A	24/03/25	10/03/26	9,97	9,97	2-MU.	70,0	697,90	12	1,5	MEC.	
1	99	CTC9006	1C	A	25/03/25	10/03/26	1,16	1,16	2-MU.	70,0	81,20	12	1,5	MEC.	
1	100	IACCTC07-7207	1C	C	25/03/25	08/05/26	1,45	1,45	1-MO.	130,0	188,50	12	1,5	MEC.	
1	101	IACCTC07-7207	1C	B	27/03/25	08/05/26	4,26	4,26	1-MO.	130,0	553,80	12	1,5	MEC.	
1	102	IACCTC07-7207	1C	A	27/03/25	08/05/26	3,98	3,98	1-MO.	130,0	517,40	12	1,5	MEC.	
1	103	IACCTC07-7207	1C	B	27/03/25	08/05/26	11,33	11,33	1-MO.	130,0	1.472,90	12	1,5	MEC.	
1	104	IACCTC07-7207	1C	B	29/03/25	08/05/26	19,47	19,47	1-MO.	130,0	2.531,10	12	1,5	MEC.	
1	131	CTC9007	3C	B	01/04/23	03/10/25	1,82	1,82	1-MO.	71,0	129,22	12	1,5	MEC.	
1	132	CTC9007	4C	B	04/04/22	03/10/25	0,69	0,69	1-MO.	71,0	48,99	12	1,5	MEC.	
1	133	CTC9007	4C	B	04/04/22	03/10/25	10,66	10,66	1-MO.	71,0	756,86	12	1,5	MEC.	
1	134	CTC9007	4C	B	04/04/22	03/10/25	15,58	15,58	1-MO.	71,0	1.106,18	12	1,5	MEC.	
1	135	CTC9007	4C	B	04/04/22	03/10/25	4,08	4,08	1-MO.	71,0	289,68	12	1,5	MEC.	
1	136	CTC9007	4C	B	05/04/22	03/10/25	2,00	2,00	1-MO.	71,0	142,00	12	1,5	MEC.	
1	137	CTC9007	4C	B	04/04/22	03/10/25	2,45	2,45	1-MO.	71,0	173,95	12	1,5	MEC.	
1	138	CTC9007	4C	B	04/04/22	03/10/25	8,30	8,30	1-MO.	71,0	589,30	12	1,5	MEC.	
1	139	CTC2	4C	B	07/04/22	03/10/25	2,46	2,46	1-MO.	71,0	174,66	12	1,5	MEC.	
1	139	CTC9007	4C	B	07/04/22	03/10/25	1,15	1,15	1-MO.	71,0	81,65	12	1,5	MEC.	
Total/Média (1 / 19 · TAQUARUÇU)							613,79	415,78		82,2	34.167,90				

N: 7713853.634
E: 335030.8915
LAT: −20°40'4.1716" (−20.66782545)
LONG: −46°35'2.6806" (−46.58407794)

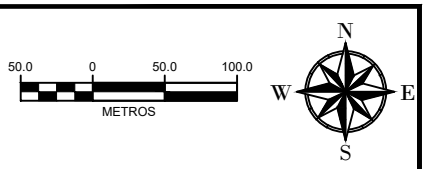

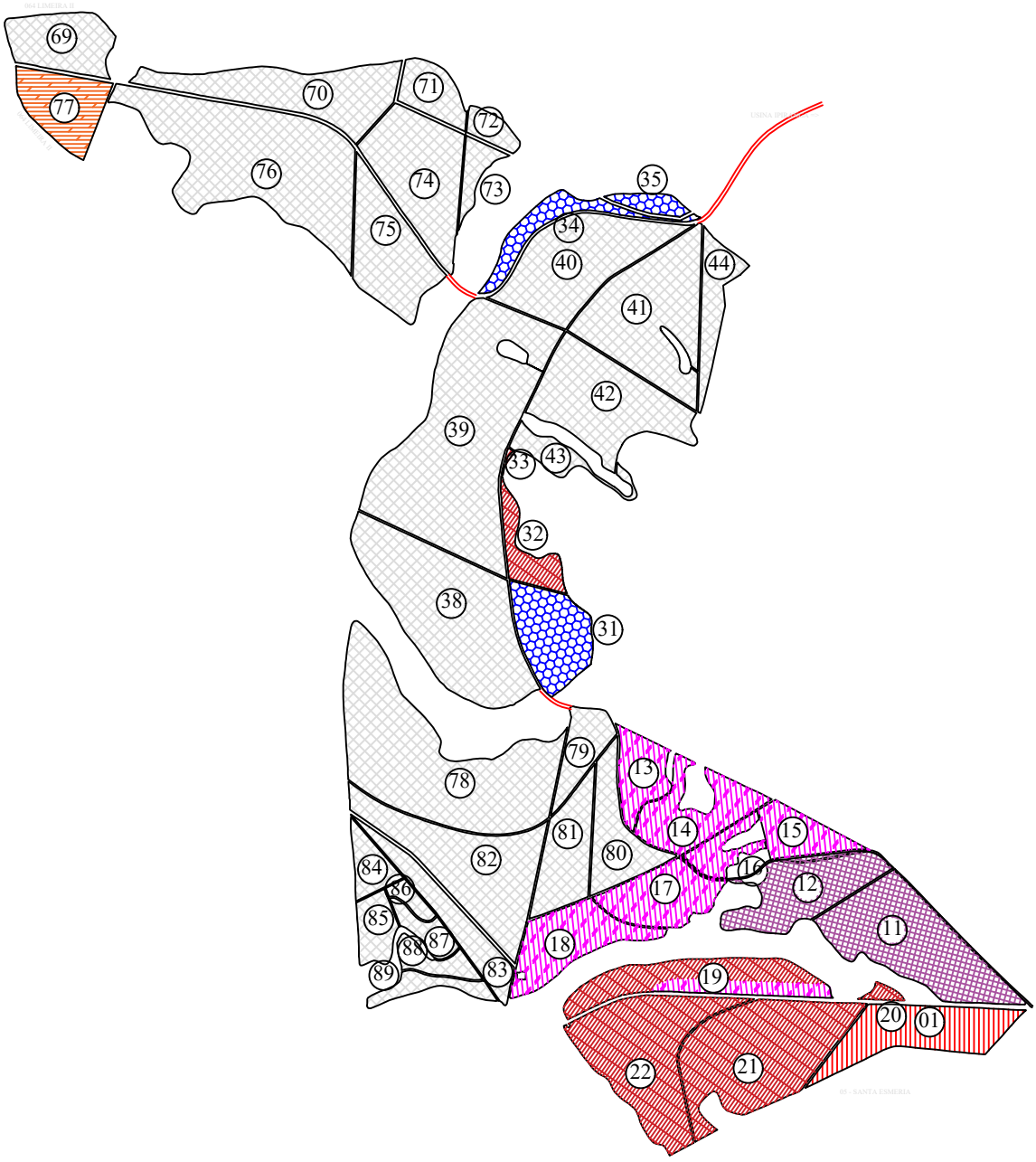

- CTC - 4
- RB 01-5177
- CT 02-2994
- RB 85-5453
- CTC - 9001
- IAC SP 04-6007
- IAC CTC 07-8008

TABELA DE VARIEDADE

VARIEDADE	ÁREA
CTC2994	26,70
CTC4	196,43
CTC9001	4,99
IACCTC07-8008	19,21
IACSP04-6007	10,00
RB015177	33,85
RB855453	7,35
Total Geral	**298,53**

IPIRANGA AGROINDUSTRIAL

PROJETO	DATA	ESCALA	TOPÓGRAFO
CADERNO DE MAPA 26'27	20/01/2026	1:5000	CRISTIAN
FAZENDA	**MUNICÍPIO**		**ÁREA (ha)**
020 - TRÊS ILHAS	PASSOS - MG		298,53
PROPRIETÁRIO	**UNIDADE**		**CÓDIGO**
AGRO PECUÁRIA VALE DO RIO GRANDE	IPIRANGA PASSOS S.A.		020

Caderno de Mapas

Bloco	Talhao	Variedade	Estágio de Corte	Amb. Prod.	Data Plantio	Último Corte	Área (ha)	Estimativas Área (ha)	Finalid	Produt.	Prod. Total	Dist.	Esp.	Tipo Corte	Experimento
1 · REG 1			20 · TRES ILHAS				IPIRANGA AGROINDUSTRIAL S.A								
1	1	RB855453	4C	A	28/03/22	05/06/25	7,35	7,35	1-MO.	60,0	441,00	8,2	1,5	MEC.	
1	11	IACCTC07-8008	4C	A	15/07/22	14/11/25	11,98	11,98	1-MO.	52,0	622,96	8,2	1,5	MEC.	
1	12	IACCTC07-8008	4C	A	15/07/22	14/11/25	7,23	7,23	1-MO.	52,0	375,96	8,2	1,5	MEC.	
1	13	CTC2994	3C	A	22/03/23	08/08/25	3,24	3,24	1-MO.	96,0	311,04	8,2	1,5	MEC.	
1	14	CTC2994	3C	CB	19/03/23	08/08/25	5,31	5,31	1-MO.	96,0	509,76	8,2	1,5	MEC.	
1	15	CTC2994	3C	CB	18/03/23	19/02/25	3,10	3,10	1-MO.	96,0	297,60	8,2	1,5	MEC.	
1	16	CTC2994	3C	A	18/03/23	19/02/25	1,88	1,88	1-MO.	96,0	180,48	8,2	1,5	MEC.	
1	17	CTC2994	3C	A	17/03/23	19/02/25	5,14	5,14	1-MO.	96,0	493,44	8,2	1,5	MEC.	
1	18	CTC2994	3C	C	17/03/23	19/02/25	5,80	5,80	1-MO.	96,0	556,80	8,2	1,5	MEC.	
1	19	CTC2994	3C	A	07/04/23	05/06/25	2,23	2,23	1-MO.	55,0	122,65	8,2	1,5	MEC.	
1	19	RB015177	3C	A	07/04/23	05/06/25	5,33	5,33	1-MO.	55,0	293,15	8,2	1,5	MEC.	
1	20	RB015177	3C	A	28/03/23	05/06/25	0,40	0,40	1-MO.	72,0	28,80	8,2	1,5	MEC.	
1	21	RB015177	3C	A	26/02/23	05/06/25	13,61	13,61	1-MO.	72,0	979,92	8,2	1,5	MEC.	
1	22	RB015177	3C	A	27/02/23	05/06/25	11,98	11,98	1-MO.	72,0	862,56	8,2	1,5	MEC.	
1	31	IACSP04-6007	3C	A	22/03/23	31/07/25	5,91	5,91	1-MO.	72,0	425,52	8,2	1,5	MEC.	
1	32	RB015177	3C	A	22/03/23	31/07/25	2,45	2,45	1-MO.	72,0	176,40	8,2	1,5	MEC.	
1	33	RB015177	3C	A	23/03/23	31/07/25	0,08	0,08	1-MO.	72,0	5,76	8,2	1,5	MEC.	
1	34	IACSP04-6007	3C	A	22/03/23	31/07/25	2,95	2,95	1-MO.	72,0	212,40	8,2	1,5	MEC.	
1	35	IACSP04-6007	3C	A	22/03/23	31/07/25	1,14	1,14	1-MO.	72,0	82,08	8,2	1,5	MEC.	
1	38	CTC4	4C	A	26/01/22	31/07/25	17,27	17,27	1-MO.	73,0	1.260,71	8,2	1,5	MEC.	
1	39	CTC4	4C	A	26/01/22	31/07/25	25,16	25,16	1-MO.	73,0	1.836,68	8,2	1,5	MEC.	
1	40	CTC4	4C	A	26/01/22	31/07/25	10,46	10,46	1-MO.	73,0	763,58	8,2	1,5	MEC.	
1	41	CTC4	4C	A	27/01/22	31/07/25	12,41	12,41	1-MO.	73,0	905,93	8,2	1,5	MEC.	
1	42	CTC4	4C	B	28/01/22	31/07/25	10,54	10,54	1-MO.	73,0	769,42	8,2	1,5	MEC.	
1	43	CTC4	4C	A	29/01/22	31/07/25	2,10	2,10	1-MO.	73,0	153,30	8,2	1,5	MEC.	
1	44	CTC4	4C	A	29/01/22	31/07/25	3,28	3,28	1-MO.	73,0	239,44	8,2	1,5	MEC.	
1	69	CTC4	4C	A	05/02/22	25/07/25	5,19	5,19	1-MO.	70,0	363,30	8,2	1,5	MEC.	
1	70	CTC4	4C	A	06/02/22	25/07/25	9,29	9,29	1-MO.	70,0	650,30	8,2	1,5	MEC.	
1	71	CTC4	4C	A	28/01/22	25/07/25	2,85	2,85	1-MO.	70,0	199,50	8,2	1,5	MEC.	
1	72	CTC4	4C	A	29/01/22	25/07/25	1,30	1,30	1-MO.	70,0	91,00	8,2	1,5	MEC.	
1	73	CTC4	4C	A	29/01/22	25/07/25	1,46	1,46	1-MO.	70,0	102,20	8,2	1,5	MEC.	
1	74	CTC4	4C	A	01/02/22	25/07/25	9,36	9,36	1-MO.	70,0	655,20	8,2	1,5	MEC.	
1	75	CTC4	4C	A	29/01/22	25/07/25	7,49	7,49	1-MO.	70,0	524,30	8,2	1,5	MEC.	
1	76	CTC4	4C	A	06/02/22	25/07/25	19,68	19,68	1-MO.	70,0	1.377,60	8,2	1,5	MEC.	
1	77	CTC9001	4C	A	27/04/22	25/07/25	4,99	4,99	1-MO.	70,0	349,30	8,2	1,5	MEC.	
1	78	CTC4	4C	A	18/02/22	08/08/25	20,28	20,28	1-MO.	75,0	1.521,00	8,2	1,5	MEC.	
1	79	CTC4	4C	A	16/02/22	08/08/25	2,94	2,94	1-MO.	75,0	220,50	8,2	1,5	MEC.	
1	80	CTC4	4C	A	16/02/22	08/08/25	4,87	4,87	1-MO.	75,0	365,25	8,2	1,5	MEC.	
1	81	CTC4	4C	A	16/02/22	08/08/25	5,16	5,16	1-MO.	75,0	387,00	8,2	1,5	MEC.	

Caderno de Mapas

Bloco	Talhao	Variedade	Estágio de Corte	Amb. Prod.	Data Plantio	Data Último Corte	Área (ha)	Estimativas Área (ha)	Estimativas Finalid	Estimativas Produt.	Prod. Total	Dist.	Esp.	Tipo Corte	Experimento
1	82	CTC4	4C	C	16/02/22	08/08/25	11,37	11,37	1-MO.	75,0	852,75	8,2	1,5	MEC.	
1	83	CTC4	4C	C	16/02/22	08/08/25	4,27	4,27	1-MO.	75,0	320,25	8,2	1,5	MEC.	
1	84	CTC4	4C	C	17/02/22	08/08/25	1,92	1,92	1-MO.	75,0	144,00	8,2	1,5	MEC.	
1	85	CTC4	4C	C	16/02/22	08/08/25	2,23	2,23	1-MO.	75,0	167,25	8,2	1,5	MEC.	
1	86	CTC4	4C	C	16/02/22	08/08/25	0,77	0,77	1-MO.	75,0	57,75	8,2	1,5	MEC.	
1	87	CTC4	4C	C	16/02/22	08/08/25	1,47	1,47	1-MO.	75,0	110,25	8,2	1,5	MEC.	
1	88	CTC4	4C	C	16/02/22	08/08/25	1,63	1,63	1-MO.	75,0	122,25	8,2	1,5	MEC.	
1	89	CTC4	4C	C	17/02/22	08/08/25	1,68	1,68	1-MO.	75,0	126,00	8,2	1,5	MEC.	
Total/Média (1 / 20 · TRES ILHAS)							298,53	298,53		72,4	21.614,29				

N: 7726301.26206653
E: 326818.41918546
LAT: −20°33'16.7525941" (−20.55465349835)
LONG: −46°39'42.0232078" (−46.66167311328)

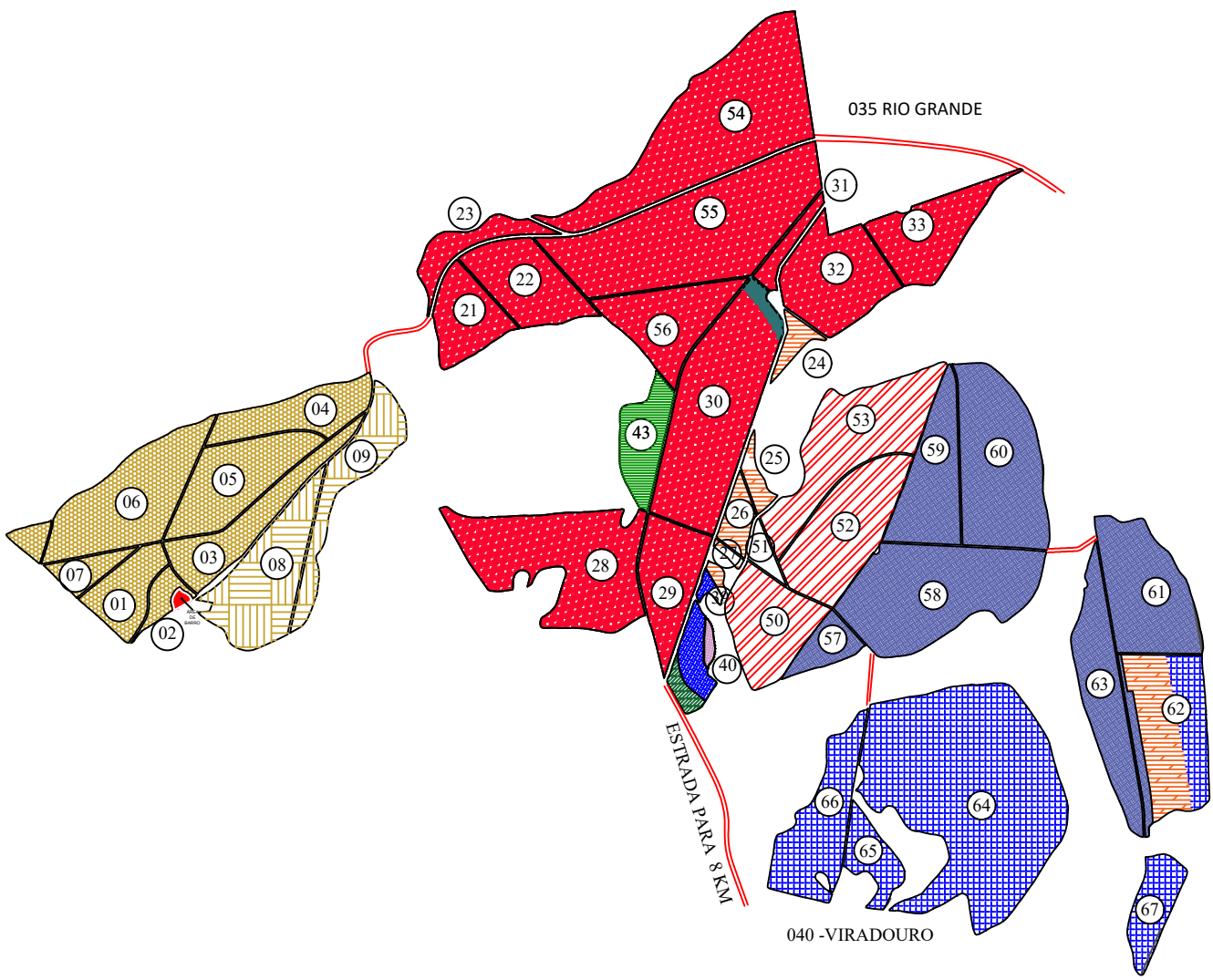

CTC - 2
RB 98-8082
VIVEIRO
RB 98-7935
CTC - 9001
CTC - 9003
CTC - 9009
CT 02-2944
RB 12-7825
IAC SP 01-5503
IAC CTC 07-7207

TABELA DE VARIEDADE

VARIEDADE	ÁREA
CTC2	50,06
CTC2994	0,70
CTC9001	9,03
CTC9003	41,73
CTC9009	0,67
IACCTC07-7207	0,34
IACSP01-5503	98,46
RB127825	32,28
RB987935	1,96
RB988082	37,94
VIVEIRO	3,53
Total Geral	**276,70**

IPIRANGA AGROINDUSTRIAL

PROJETO	DATA	ESCALA	TOPÓGRAFO
CADERNO DE MAPA 26'27	25/05/2026	1:5000	CRISTIAN
FAZENDA	**MUNICÍPIO**		**ÁREA (ha)**
021 ARADINHO	PASSOS - MG		276,70
PROPRIETÁRIO	**UNIDADE**		**CÓDIGO**
AGRO PECUÁRIA VALE DO RIO GRANDE	IPIRANGA PASSOS - MG		021

Caderno de Mapas

Bloco	Talhao	Variedade	Estágio de Corte	Amb. Prod.	Data Plantio	Último Corte	Área (ha)	Estimativas Área (ha)	Finalid	Produt.	Prod. Total	Dist.	Esp.	Tipo Corte	Experimento
1 · REG 1			**21 · ARADINHO**				**IPIRANGA AGROINDUSTRIAL S.A**								
1	1	RB127825	FORM	CB	07/03/26		3,42	0,00	.		0,00	25,3	1,5	N/D	
1	2	RB127825	FORM	A	17/03/26		1,05	0,00	.		0,00	25,3	1,5	N/D	
1	3	RB127825	FORM	A	09/03/26		5,00	0,00	.		0,00	25,3	1,5	N/D	
1	4	RB127825	FORM	A	17/03/26		4,61	0,00	.		0,00	25,3	1,5	N/D	
1	5	RB127825	FORM	A	16/03/26		6,67	0,00	.		0,00	25,3	1,5	N/D	
1	6	RB127825	FORM	A	17/03/26		10,03	0,00	.		0,00	25,3	1,5	N/D	
1	7	RB127825	FORM	CB	06/03/26		1,50	0,00	.		0,00	25,3	1,5	N/D	
1	8	RB988082	3C	A	11/10/22	22/09/25	7,75	7,75	1-MO.	65,0	503,75	25,3	1,5	MEC.	
1	9	RB988082	3C	A	06/10/22	22/09/25	5,01	5,01	1-MO.	65,0	325,65	25,3	1,5	MEC.	
1	21	IACSP01-5503	3C	CB	20/12/22	12/09/25	4,10	4,10	1-MO.	82,0	336,20	25,3	1,5	MEC.	
1	22	IACSP01-5503	3C	CB	21/12/22	12/09/25	5,69	5,69	1-MO.	82,0	466,58	25,3	1,5	MEC.	
1	23	IACSP01-5503	3C	CB	10/02/23	12/09/25	2,46	2,46	1-MO.	82,0	201,72	25,3	1,5	MEC.	
1	24	CTC9001	4C	CB	26/04/22	12/09/25	0,96	0,96	1-MO.	65,0	62,40	25,3	1,5	MEC.	
1	25	CTC9001	4C	A	26/04/22	12/09/25	0,88	0,88	1-MO.	65,0	57,20	25,3	1,5	MEC.	
1	26	CTC9001	4C	CB	26/04/22	12/09/25	1,42	1,42	1-MO.	65,0	92,30	25,3	1,5	MEC.	
1	27	CTC9001	4C	CB	26/04/22	12/09/25	0,24	0,24	1-MO.	65,0	15,60	25,3	1,5	MEC.	
1	28	IACSP01-5503	4C	CB	03/01/23	12/09/25	12,81	12,81	1-MO.	76,0	973,56	25,3	1,5	MEC.	
1	29	IACSP01-5503	4C	CB	23/01/23	12/09/25	5,23	5,23	1-MO.	76,0	397,48	25,3	1,5	MEC.	
1	30	CTC9009	3C	CB	05/02/23	12/09/25	0,67	0,67	1-MO.	76,0	50,92	25,3	1,5	MEC.	
1	30	IACSP01-5503	3C	CB	05/02/23	12/09/25	13,59	13,59	1-MO.	76,0	1.032,84	25,3	1,5	MEC.	
1	31	IACSP01-5503	3C	CB	10/02/23	12/09/25	1,14	1,14	1-MO.	76,0	86,64	25,3	1,5	MEC.	
1	32	IACSP01-5503	3C	CB	10/02/23	12/09/25	7,34	7,34	1-MO.	76,0	557,84	25,3	1,5	MEC.	
1	33	IACSP01-5503	3C	CB	13/02/23	12/09/25	5,75	5,75	1-MO.	76,0	437,00	25,3	1,5	MEC.	
1	39	CTC9001	4C	CB	26/04/22	14/11/25	0,29	0,29	1-MO.	65,0	18,85	25,3	1,5	MEC.	
1	39	RB987935	4C	CB	26/04/22	14/11/25	0,33	0,33	1-MO.	65,0	21,45	25,3	1,5	MEC.	
1	40	CTC2994	4C	CB	26/04/22	14/11/25	0,70	0,70	1-MO.	65,0	45,50	25,3	1,5	MEC.	
1	40	IACCTC07-7207	4C	CB	26/04/22	14/11/25	0,34	0,34	1-MO.	65,0	22,10	25,3	1,5	MEC.	
1	40	RB987935	4C	CB	26/04/22	14/11/25	1,63	1,63	1-MO.	65,0	105,95	25,3	1,5	MEC.	
1	43	VIVEIRO	4C	CB	20/01/23	12/09/25	3,53	3,53	1-MO.	65,0	229,45	25,3	1,5	MEC.	
1	50	RB988082	5C	CB	02/02/21	14/11/25	6,11	6,11	1-MO.	65,0	397,15	25,3	1,5	MEC.	
1	51	RB988082	5C	CB	02/02/21	14/11/25	0,78	0,78	1-MO.	65,0	50,70	25,3	1,5	MEC.	
1	52	RB988082	5C	CB	02/02/21	14/11/25	8,35	8,35	1-MO.	65,0	542,75	25,3	1,5	MEC.	
1	53	RB988082	5C	A	02/02/21	14/11/25	9,94	9,94	1-MO.	65,0	646,10	25,3	1,5	MEC.	
1	54	IACSP01-5503	3C	A	10/02/23	12/09/25	17,13	17,13	1-MO.	75,0	1.284,75	25,3	1,5	MEC.	
1	55	IACSP01-5503	3C	A	06/02/23	12/09/25	17,30	17,30	1-MO.	70,0	1.211,00	25,3	1,5	MEC.	
1	56	IACSP01-5503	3C	CB	31/01/23	12/09/25	5,92	5,92	1-MO.	70,0	414,40	25,3	1,5	MEC.	
1	57	CTC9003	4C	CB	17/03/22	14/11/25	1,97	1,97	1-MO.	69,0	135,93	25,3	1,5	MEC.	
1	58	CTC9003	4C	A	26/04/22	14/11/25	12,93	12,93	1-MO.	69,0	892,17	25,3	1,5	MEC.	
1	59	CTC9003	4C	A	26/04/22	14/11/25	6,35	6,35	1-MO.	69,0	438,15	25,3	1,5	MEC.	

Caderno de Mapas

Bloco	Talhao	Variedade	Estágio de Corte	Amb. Prod.	Data Plantio	Data Último Corte	Área (ha)	Estimativas Área (ha)	Estimativas Finalid	Estimativas Produt.	Prod. Total	Dist.	Esp.	Tipo Corte	Experimento
1	60	CTC9003	4C	A	26/04/22	14/11/25	11,07	11,07	1-MO.	69,0	763,83	25,3	1,5	MEC.	
1	61	CTC9003	4C	A	26/04/22	14/11/25	8,30	8,30	1-MO.	69,0	572,70	25,3	1,5	MEC.	
1	62	CTC2	4C	A	26/04/22	14/11/25	3,34	3,34	1-MO.	65,0	217,10	25,3	1,5	MEC.	
1	62	CTC9001	4C	A	26/04/22	14/11/25	5,24	5,24	1-MO.	65,0	340,60	25,3	1,5	MEC.	
1	62	CTC9003	4C	A	26/04/22	14/11/25	1,11	1,11	1-MO.	65,0	72,15	25,3	1,5	MEC.	
1	63	CTC2	4C	A	26/04/22	14/11/25	6,80	6,80	1-MO.	69,0	469,20	25,3	1,5	MEC.	
1	64	CTC2	4C	C	26/04/22	14/11/25	27,60	27,60	1-MO.	69,0	1.904,40	25,3	1,5	MEC.	
1	65	CTC2	4C	C	26/04/22	14/11/25	2,50	2,50	1-MO.	69,0	172,50	25,3	1,5	MEC.	
1	66	CTC2	4C	C	26/04/22	14/11/25	6,75	6,75	1-MO.	69,0	465,75	25,3	1,5	MEC.	
1	67	CTC2	4C	A	26/04/22	14/11/25	3,07	3,07	1-MO.	69,0	211,83	25,3	1,5	MEC.	
Total/Média (1 / 21 · ARADINHO)							276,70	244,42		70,6	17.244,14				

N: 7725614.10934988
E: 326060.21945753
LAT: −20°33'38.8444978" (−20.56079013828)
LONG: −46°40'8.4412747" (−46.66901146520)

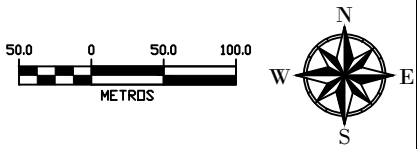

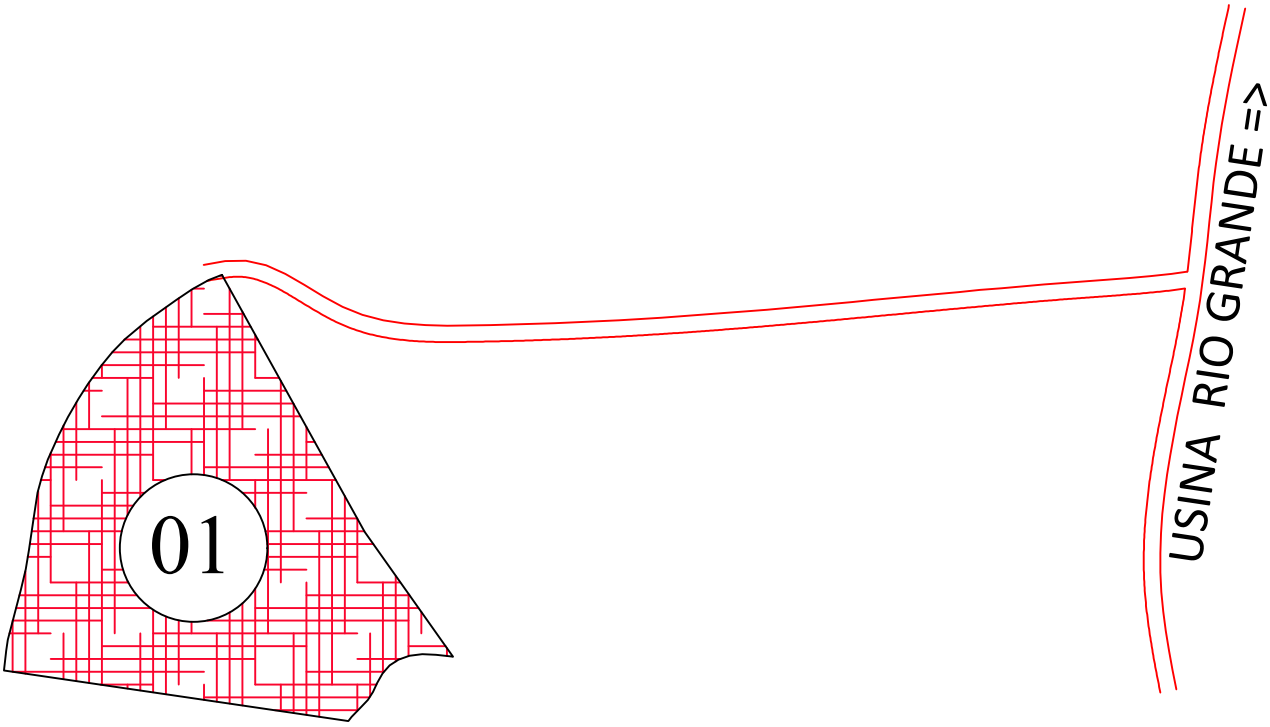

IAC SP 01-5503

TABELA DE VARIEDADE	
VARIEDADE	ÁREA
IACSP01-5503	4,30
Total Geral	**4,30**

IPIRANGA AGROINDUSTRIAL	PROJETO: CADERNO DE MAPA 26'27	DATA: 20/01/2026	ESCALA: 1:5000	TOPÓGRAFO: CRISTIAN
	FAZENDA: 022 - VIRADOURO	MUNICÍPIO: PASSOS - MG		ÁREA (ha): 4,30
	PROPRIETÁRIO: AGRO PECUÁRIA VALE DO RIO GRANDE	UNIDADE: IPIRANGA PASSOS - MG		CÓDIGO: 022

Caderno de Mapas

Bloco	Talhao	Variedade	Estágio de Corte	Amb. Prod.	Data Plantio	Último Corte	Área (ha)	Estimativas Área (ha)	Finalid	Produt.	Prod. Total	Dist.	Esp.	Tipo Corte	Experimento
1 · REG 1			**22 · VIRADOURO**				**IPIRANGA AGROINDUSTRIAL S.A**								
1	1	IACSP01-5503	4C	A	24/02/23	12/09/25	4,30	4,30	1-MO.	69,0	296,70	25,7	1,5	MEC.	
Total/Média (1 / 22 · VIRADOURO)							4,30	4,30		69,0	296,70				

N: 7725530.391
E: 330117.2611
LAT: -20°33'42.9010" (-20.56191694)
LONG: -46°37'48.4019" (-46.63011164)

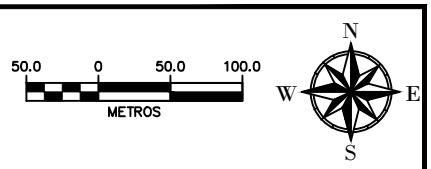

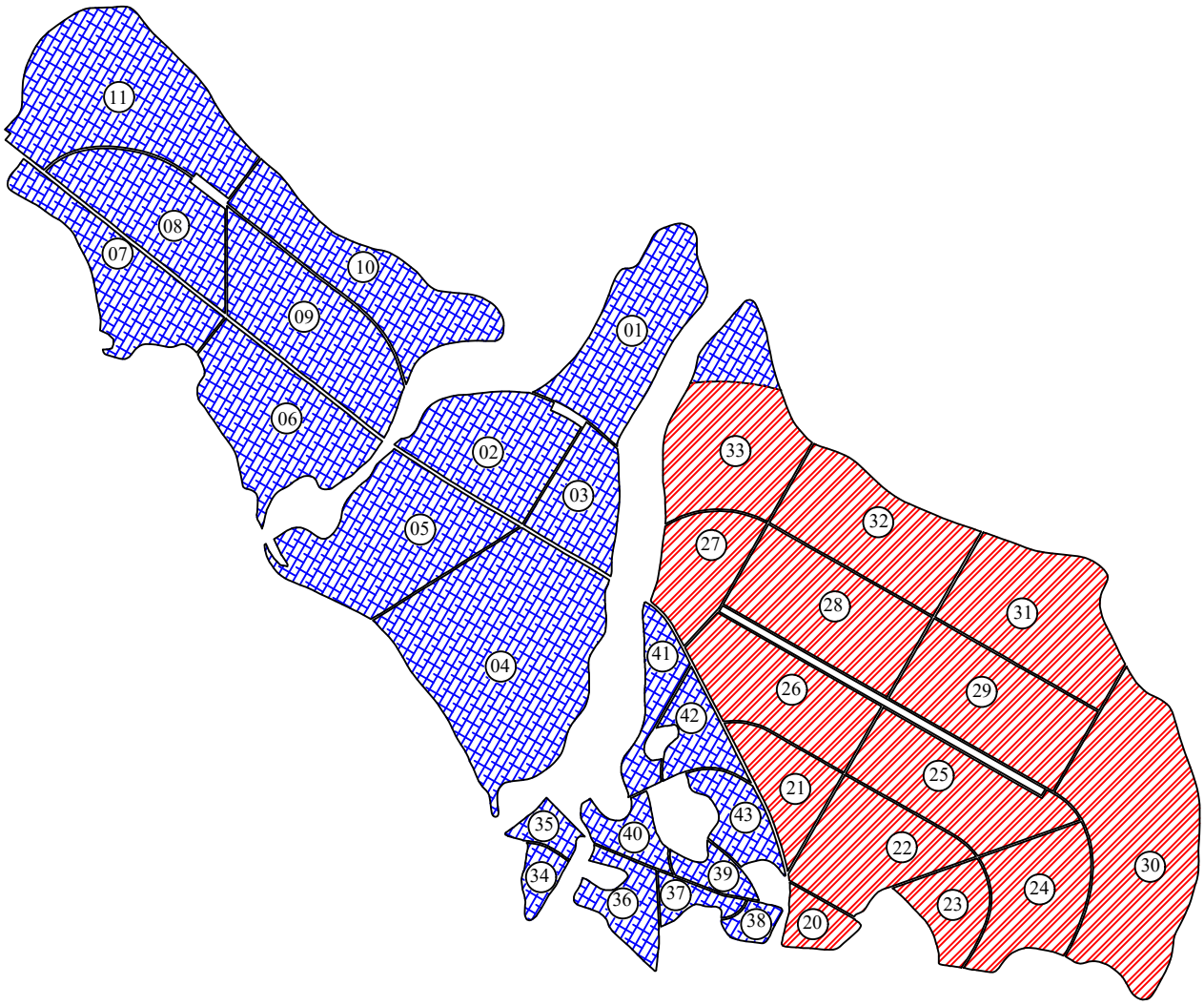

RB 98-8082
RB 98-7935

TABELA DE VARIEDADE

VARIEDADE	ÁREA
RB987935	169,25
RB988082	137,94
Total Geral	**307,19**

IPIRANGA AGROINDUSTRIAL

PROJETO: CADERNO DE MAPA 26'27	DATA: 20/01/2026	ESCALA: 1:5000	TOPÓGRAFO: CRISTIAN
FAZENDA: 023 - BARRA DA BOCAINA	MUNICÍPIO: PASSOS MG		ÁREA (ha): 307,19
PROPRIETÁRIO: ITAIQUARA ALIMENTOS	UNIDADE: IPIRANGA PASSOS		CÓDIGO: 023

Caderno de Mapas

Bloco	Talhao	Variedade	Estágio de Corte	Amb. Prod.	Data Plantio	Último Corte	Área (ha)	Estimativas Área (ha)	Finalid	Produt.	Prod. Total	Dist.	Esp.	Tipo Corte	Experimento
1 · REG 1			**23 · BARRA BOCAINA**				**IPIRANGA AGROINDUSTRIAL S.A**								
1	1	RB987935	3C	A	18/11/22	03/10/25	11,42	11,42	1-MO.	75,0	856,50	21,4	1,5	MEC.	
1	2	RB987935	3C	A	18/11/22	03/10/25	10,08	10,08	1-MO.	75,0	756,00	21,4	1,5	MEC.	
1	3	RB987935	3C	A	18/11/22	03/10/25	5,93	5,93	1-MO.	75,0	444,75	21,4	1,5	MEC.	
1	4	RB987935	3C	B	22/11/22	03/10/25	25,72	25,72	1-MO.	75,0	1.929,00	21,4	1,5	MEC.	
1	5	RB987935	3C	B	22/11/22	03/10/25	14,37	14,37	1-MO.	75,0	1.077,75	21,4	1,5	MEC.	
1	6	RB987935	3C	B	21/11/22	19/09/25	12,49	12,49	1-MO.	70,0	874,30	21,4	1,5	MEC.	
1	7	RB987935	3C	B	20/11/22	19/09/25	9,19	9,19	1-MO.	70,0	643,30	21,4	1,5	MEC.	
1	8	RB987935	3C	A	20/11/22	19/09/25	9,87	9,87	1-MO.	70,0	690,90	21,4	1,5	MEC.	
1	9	RB987935	3C	A	18/11/22	19/09/25	12,72	12,72	1-MO.	70,0	890,40	21,4	1,5	MEC.	
1	10	RB987935	3C	A	20/11/22	19/09/25	11,67	11,67	1-MO.	70,0	816,90	21,4	1,5	MEC.	
1	11	RB987935	3C	A	19/11/22	19/09/25	18,48	18,48	1-MO.	70,0	1.293,60	21,4	1,5	MEC.	
1	20	RB988082	4C	A	25/02/22	03/10/25	2,23	2,23	1-MO.	65,0	144,95	21,4	1,5	MEC.	
1	21	RB988082	4C	A	23/02/22	03/10/25	5,13	5,13	1-MO.	65,0	333,45	21,4	1,5	MEC.	
1	22	RB988082	4C	A	23/02/22	03/10/25	9,27	9,27	1-MO.	65,0	602,55	21,4	1,5	MEC.	
1	23	RB988082	4C	A	24/02/22	03/10/25	4,13	4,13	1-MO.	65,0	268,45	21,4	1,5	MEC.	
1	24	RB988082	4C	A	23/02/22	03/10/25	8,29	8,29	1-MO.	65,0	538,85	21,4	1,5	MEC.	
1	25	RB988082	4C	A	16/02/22	03/10/25	10,54	10,54	1-MO.	65,0	685,10	21,4	1,5	MEC.	
1	26	RB988082	4C	A	06/02/22	03/10/25	10,27	10,27	1-MO.	65,0	667,55	21,4	1,5	MEC.	
1	27	RB988082	5C	A	17/02/22	03/10/25	6,28	6,28	1-MO.	65,0	408,20	21,4	1,5	MEC.	
1	28	RB988082	5C	A	17/02/22	03/10/25	12,09	12,09	1-MO.	65,0	785,85	21,4	1,5	MEC.	
1	29	RB988082	4C	A	23/02/22	03/10/25	12,09	12,09	1-MO.	65,0	785,85	21,4	1,5	MEC.	
1	30	RB988082	4C	A	24/02/22	03/10/25	21,01	21,01	1-MO.	65,0	1.365,65	21,4	1,5	MEC.	
1	31	RB988082	4C	A	24/02/22	03/10/25	13,36	13,36	1-MO.	65,0	868,40	21,4	1,5	MEC.	
1	32	RB988082	4C	A	19/02/22	03/10/25	12,00	12,00	1-MO.	65,0	780,00	21,4	1,5	MEC.	
1	33	RB987935	4C	A	09/02/22	03/10/25	3,20	3,20	1-MO.	65,0	208,00	21,4	1,5	MEC.	
1	33	RB988082	4C	A	09/02/22	03/10/25	11,25	11,25	1-MO.	65,0	731,25	21,4	1,5	MEC.	
1	34	RB987935	3C	A	01/03/23	03/10/25	1,49	1,49	1-MO.	75,0	111,75	21,4	1,5	MEC.	
1	35	RB987935	3C	A	01/03/23	03/10/25	1,52	1,52	1-MO.	75,0	114,00	21,4	1,5	MEC.	
1	36	RB987935	3C	A	23/02/23	03/10/25	3,64	3,64	1-MO.	75,0	273,00	21,4	1,5	MEC.	
1	37	RB987935	3C	A	20/02/23	03/10/25	1,53	1,53	1-MO.	75,0	114,75	21,4	1,5	MEC.	
1	38	RB987935	3C	A	20/02/23	03/10/25	1,17	1,17	1-MO.	75,0	87,75	21,4	1,5	MEC.	
1	39	RB987935	3C	A	28/02/23	03/10/25	1,69	1,69	1-MO.	75,0	126,75	21,4	1,5	MEC.	
1	40	RB987935	3C	A	01/03/23	03/10/25	2,50	2,50	1-MO.	75,0	187,50	21,4	1,5	MEC.	
1	41	RB987935	3C	A	28/02/23	03/10/25	3,57	3,57	1-MO.	75,0	267,75	21,4	1,5	MEC.	
1	42	RB987935	3C	A	26/02/23	03/10/25	3,46	3,46	1-MO.	75,0	259,50	21,4	1,5	MEC.	
1	43	RB987935	3C	A	21/02/23	03/10/25	3,54	3,54	1-MO.	75,0	265,50	21,4	1,5	MEC.	
Total/Média (1 / 23 · BARRA BOCAINA)							307,19	307,19		69,2	21.255,75				

N: 7723668.104
E: 325173.3044
LAT: −20°34'41.8249" (−20.57828468)
LONG: −46°40'39.7527" (−46.67770909)

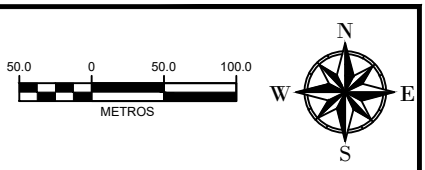

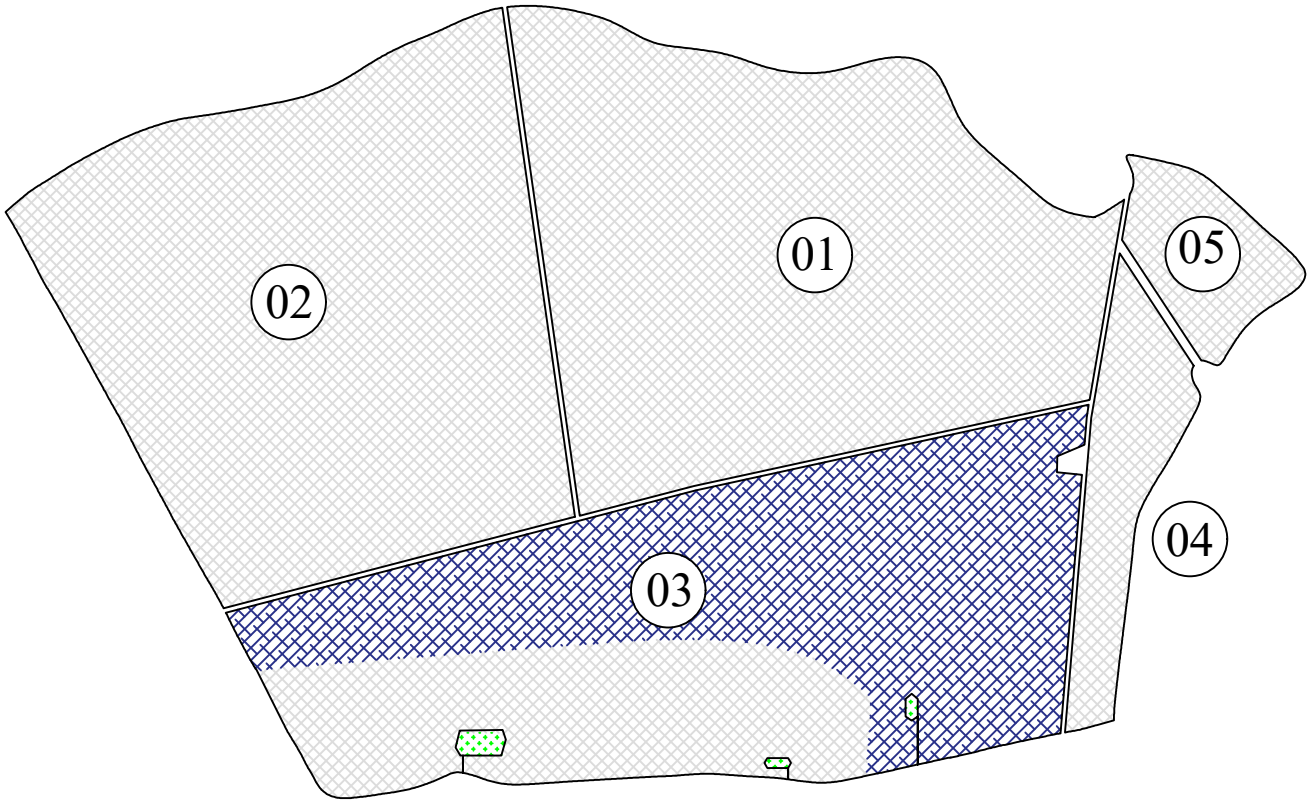

CTC - 4

RB 98-7935

TABELA DE VARIEDADE

VARIEDADE	ÁREA
CTC4	63,56
RB987935	16,63
Total Geral	**80,19**

IPIRANGA AGROINDUSTRIAL

PROJETO: CADERNO DE MAPA 26'27	DATA: 20/01/2026	ESCALA: 1:5000	TOPÓGRAFO: CRISTIAN
FAZENDA: 024 - BARRA DOCE	MUNICÍPIO: PASSOS - MG		ÁREA (ha): 80,19
PROPRIETÁRIO: CIA.AGRO PASTORIO DO RIO GRANDE	UNIDADE: IPIRANGA - PASSOS		CÓDIGO: 024

Caderno de Mapas

Bloco	Talhao	Variedade	Estágio de Corte	Amb. Prod.	Data Plantio	Data Último Corte	Área (ha)	Estimativas Área (ha)	Estimativas Finalid	Estimativas Produt.	Prod. Total	Dist.	Esp.	Tipo Corte	Experimento
1 · REG 1			**24 · BARRA DOCE I**				**IPIRANGA AGROINDUSTRIAL S.A**								
1	1	CTC4	5C	BA	15/04/21	27/11/25	24,16	24,16	1-MO.	55,0	1.328,80	30,3	1,5	MEC.	
1	2	CTC4	5C	BA	15/04/21	27/11/25	25,09	25,09	1-MO.	55,0	1.379,95	30,3	1,5	MEC.	
1	3	CTC4	5C	A	15/04/21	27/11/25	8,54	8,54	1-MO.	55,0	469,70	30,3	1,5	MEC.	
1	3	RB987935	5C	A	15/04/21	27/11/25	16,63	16,63	1-MO.	55,0	914,65	30,3	1,5	MEC.	
1	4	CTC4	5C	BA	17/04/21	27/11/25	3,30	3,30	1-MO.	55,0	181,50	30,3	1,5	MEC.	
1	5	CTC4	5C	BA	16/04/21	27/11/25	2,47	2,47	1-MO.	55,0	135,85	30,3	1,5	MEC.	
Total/Média (1 / 24 · BARRA DOCE I)							80,19	80,19		55,0	4.410,45				

N: 7728490.39906472
E: 325412.95689486
LAT: −20°32'5.1030627" (−20.53475085074)
LONG: −46°40'29.7683957" (−46.67493566546)

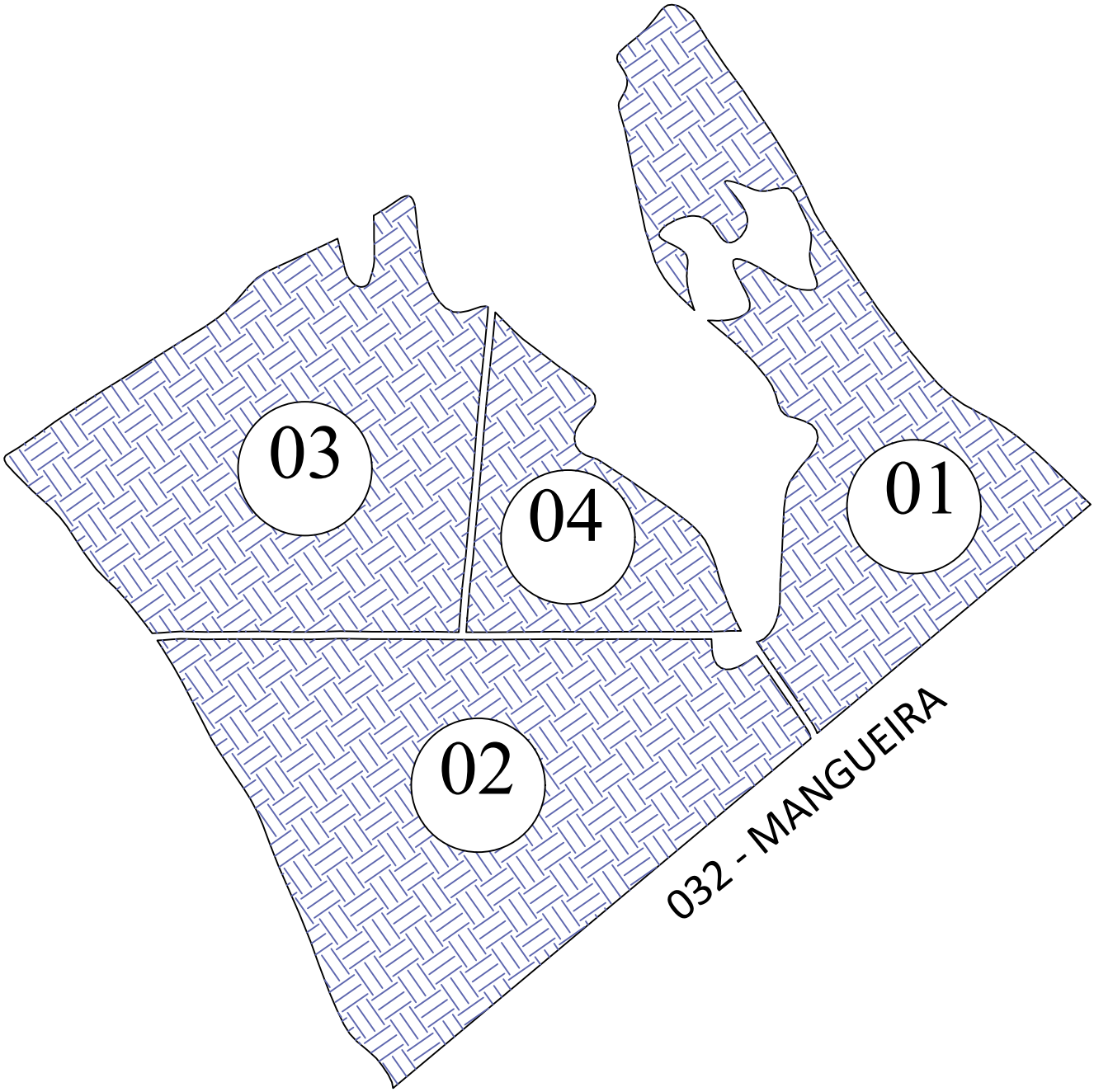

CTC - 9003

TABELA DE VARIEDADE	
VARIEDADE	ÁREA
CTC9003	20,56
Total Geral	**20,56**

IPIRANGA AGROINDUSTRIAL	PROJETO: CADERNO DE MAPA 26'27	DATA: 20/01/2026	ESCALA: 1:5000	TOPÓGRAFO: CRISTIAN
	FAZENDA: 025 - BARRINHA	MUNICÍPIO: PASSOS - MG		ÁREA (ha): 20,56
	PROPRIETÁRIO: CIA.AGRO PASTORIO DO RIO GRANDE	UNIDADE: IPIRANGA - PASSOS		CÓDIGO: 025

Caderno de Mapas

Bloco	Talhao	Variedade	Estágio de Corte	Amb. Prod.	Data Plantio	Último Corte	Área (ha)	Estimativas Área (ha)	Finalid	Produt.	Prod. Total	Dist.	Esp.	Tipo Corte	Experimento
1 · REG 1			**25 · BARRINHA I**				**IPIRANGA AGROINDUSTRIAL S.A**								
1	1	CTC9003	3C	BA	29/11/22	10/09/25	5,01	5,01	1-MO.	60,0	300,60	29,8	1,5	MEC.	
1	2	CTC9003	3C	B	28/11/22	10/09/25	7,39	7,39	1-MO.	60,0	443,40	29,8	1,5	MEC.	
1	3	CTC9003	3C	B	28/11/22	10/09/25	5,99	5,99	1-MO.	60,0	359,40	29,8	1,5	MEC.	
1	4	CTC9003	3C	B	28/11/22	10/09/25	2,17	2,17	1-MO.	60,0	130,20	29,8	1,5	MEC.	
Total/Média (1 / 25 · BARRINHA I)							20,56	20,56		60,0	1.233,60				

N: 7719689.140
E: 320707.2671
LAT: −20°36'49.6873" (−20.61380203)
LONG: −46°43'15.4067" (−46.72094630)

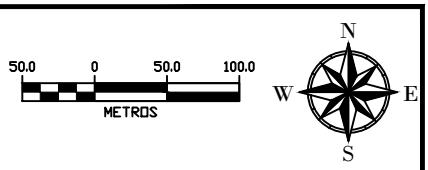

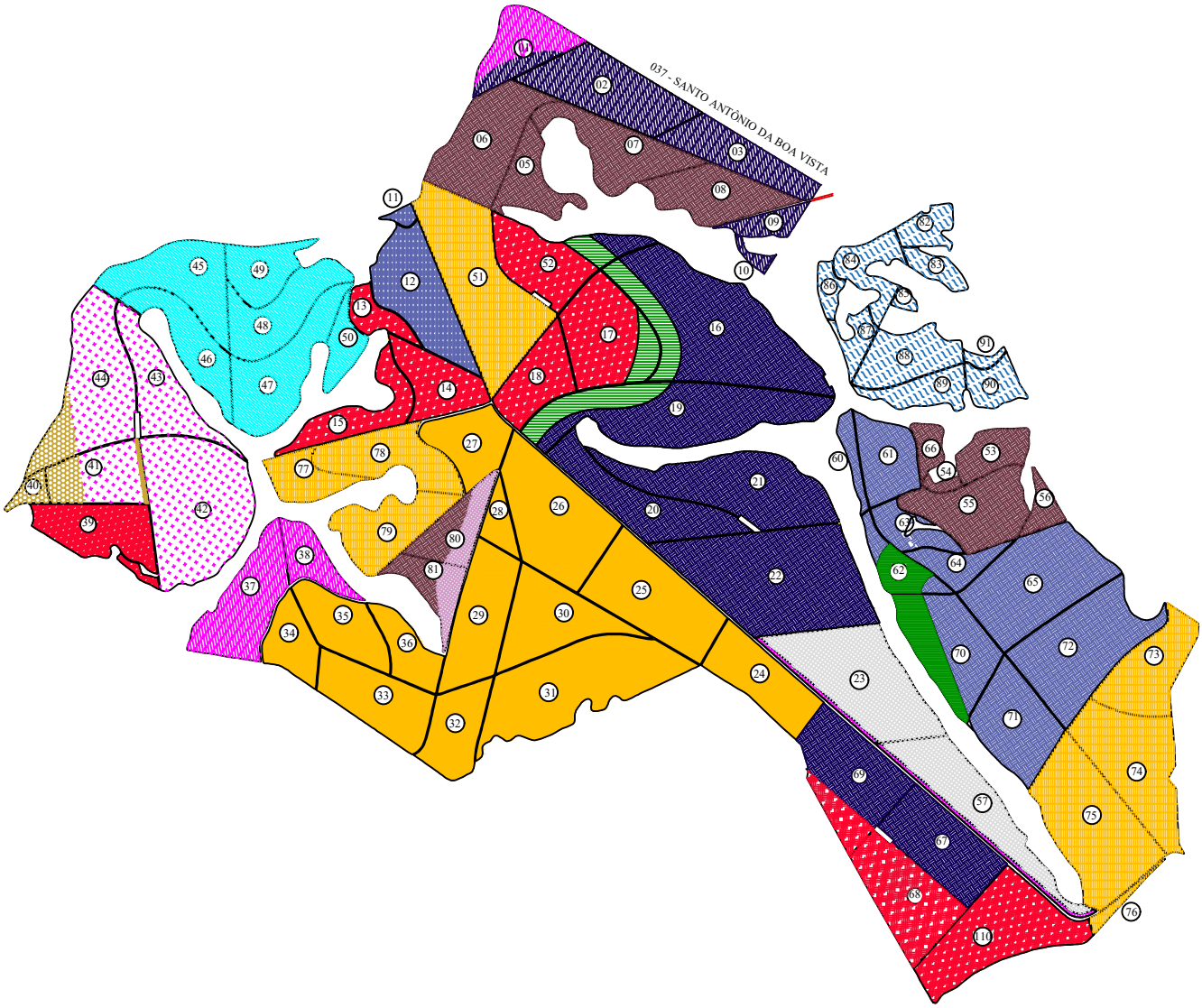

- CTC - 4
- VIVEIRO
- CV-7870
- CTC - 2519
- CTC -3445
- CTC - 9003
- CTC - 9006
- CTC - 9008
- RB 12-7825
- RB 98-5476
- CTC -2994
- SP 80-1816
- RB 96-6928
- IACSP02-1064
- IAC SP 01-5503
- IAC CTC 07-7207

TABELA DE VARIEDADE

VARIEDADE	ÁREA
CTC2519	57,07
CTC2994	23,89
CTC3445	36,66
CTC4	35,13
CTC9003	79,76
CTC9006	223,14
CTC9008	35,91
CV7870	33,05
IACCTC07-7207	5,74
IACSP01-5503	96,28
IACSP02-1064	20,22
RB127825	31,39
RB966928	3,22
RB985476	104,56
SP80-1816	156,84
VIVEIRO	24,42
Total Geral	**967,28**

IPIRANGA AGROINDUSTRIAL

PROJETO	DATA	ESCALA	TOPÓGRAFO
CADERNO DE MAPA 26'27	20/01/2026	1:5000	CRISTIAN

FAZENDA	MUNICÍPIO	ÁREA (ha)
026 - BOA VISTA	PASSOS - MG	967,28

PROPRIETÁRIO	UNIDADE	CÓDIGO
IPIRANGA AGROINDUSTRIAL	IPIRANGA PASSOS - MG	026

Caderno de Mapas

Bloco	Talhao	Variedade	Estágio de Corte	Amb. Prod.	Data Plantio	Último Corte	Área (ha)	Estimativas Área (ha)	Finalid	Produt.	Prod. Total	Dist.	Esp.	Tipo Corte	Experimento
1 · REG 1			26 · BOA VISTA				IPIRANGA AGROINDUSTRIAL S.A								
1	1	CTC2994	3C	BA	19/04/23	20/06/25	5,44	5,44	1-MO.	93,0	505,92	35	1,5	MEC.	
1	1	CV7870	3C	BA	19/04/23	20/06/25	3,91	3,91	1-MO.	93,0	363,63	35	1,5	MEC.	
1	2	CV7870	3C	BA	13/04/23	20/06/25	15,59	15,59	1-MO.	93,0	1.449,87	35	1,5	MEC.	
1	3	CV7870	3C	BA	11/04/23	20/06/25	9,61	9,61	1-MO.	93,0	893,73	35	1,5	MEC.	
1	5	CTC9006	3C	A	22/04/23	20/06/25	6,84	6,84	1-MO.	93,0	636,12	35	1,5	MEC.	
1	6	CTC9006	3C	A	22/04/23	20/06/25	15,18	15,18	1-MO.	93,0	1.411,74	35	1,5	MEC.	
1	7	CTC9006	3C	BA	13/04/23	20/06/25	11,65	11,65	1-MO.	93,0	1.083,45	35	1,5	MEC.	
1	8	CTC9006	3C	B	13/04/23	20/06/25	10,56	10,56	1-MO.	93,0	982,08	35	1,5	MEC.	
1	9	CV7870	3C	B	17/04/23	20/06/25	3,03	3,03	1-MO.	93,0	281,79	35	1,5	MEC.	
1	10	CV7870	3C	CB	18/04/23	08/08/25	0,91	0,91	1-MO.	93,0	84,63	35	1,5	MEC.	
1	11	IACSP01-5503	2C	BA	29/02/24	24/02/25	0,83	0,83	1-MO.	93,0	77,19	35	1,5	MEC.	
1	12	IACSP01-5503	2C	BA	01/03/24	09/07/25	14,71	14,71	1-MO.	93,0	1.368,03	35	1,5	MEC.	
1	13	IACSP02-1064	2C	A	02/03/24	09/07/25	3,63	3,63	1-MO.	110,0	399,30	35	1,5	MEC.	
1	14	IACSP02-1064	2C	A	02/03/24	09/07/25	8,65	8,65	1-MO.	110,0	951,50	35	1,5	MEC.	
1	15	IACSP02-1064	2C	A	02/03/24	09/07/25	7,94	7,94	1-MO.	110,0	873,40	35	1,5	MEC.	
1	16	CTC9006	FORM	BA	16/02/26		33,36	0,00	.		0,00	35	1,5	N/D	
1	17	IACSP01-5503	FORM	BA	14/01/26		13,10	0,00	.		0,00	35	1,5	N/D	
1	17	VIVEIRO	FORM	BA	14/01/26		2,60	0,00	.		0,00	35	1,5	N/D	
1	18	IACSP01-5503	FORM	BA	13/01/26		8,77	0,00	.		0,00	35	1,5	N/D	
1	19	CTC9006	FORM	BA	19/02/26		20,78	0,00	.		0,00	35	1,5	N/D	
1	19	VIVEIRO	FORM	BA	19/02/26		6,00	0,00	.		0,00	35	1,5	N/D	
1	20	CTC9006	FORM	BA	16/02/26		13,47	0,00	.		0,00	35	1,5	N/D	
1	21	CTC9006	FORM	BA	19/02/26		20,26	0,00	.		0,00	35	1,5	N/D	
1	22	CTC9006	FORM	BA	02/03/26		32,09	0,00	.		0,00	35	1,5	N/D	
1	23	CTC4	5C	BA	31/10/21	18/07/25	21,07	21,07	1-MO.	60,0	1.264,20	35	1,5	MEC.	
1	23	RB966928	5C	BA	31/10/21	18/07/25	1,16	1,16	1-MO.	60,0	69,60	35	1,5	MEC.	
1	24	SP80-1816	4C	BA	24/02/22	08/08/25	11,40	11,40	1-MO.	60,0	684,00	35	1,5	MEC.	
1	25	SP80-1816	4C	B	24/02/22	08/08/25	18,36	18,36	1-MO.	60,0	1.101,60	35	1,5	MEC.	
1	26	SP80-1816	4C	B	27/02/22	08/08/25	20,24	20,24	1-MO.	60,0	1.214,40	35	1,5	MEC.	
1	27	SP80-1816	4C	BA	01/03/22	08/08/25	8,86	8,86	1-MO.	60,0	531,60	35	1,5	MEC.	
1	28	SP80-1816	4C	B	02/03/22	08/08/25	3,09	3,09	1-MO.	60,0	185,40	35	1,5	MEC.	
1	29	SP80-1816	4C	B	01/03/22	08/08/25	13,79	13,79	1-MO.	60,0	827,40	35	1,5	MEC.	
1	30	SP80-1816	4C	B	24/02/22	08/08/25	13,38	13,38	1-MO.	60,0	802,80	35	1,5	MEC.	
1	31	SP80-1816	4C	BA	24/02/22	08/08/25	24,82	24,82	1-MO.	60,0	1.489,20	35	1,5	MEC.	
1	32	SP80-1816	4C	A	01/03/22	08/08/25	8,96	8,96	1-MO.	60,0	537,60	35	1,5	MEC.	
1	33	SP80-1816	4C	A	01/03/22	08/08/25	12,36	12,36	1-MO.	60,0	741,60	35	1,5	MEC.	
1	34	SP80-1816	4C	A	01/03/22	08/08/25	6,34	6,34	1-MO.	60,0	380,40	35	1,5	MEC.	
1	35	SP80-1816	4C	A	01/03/22	08/08/25	9,18	9,18	1-MO.	60,0	550,80	35	1,5	MEC.	
1	36	SP80-1816	4C	A	01/03/22	08/08/25	6,06	6,06	1-MO.	60,0	363,60	35	1,5	MEC.	

Caderno de Mapas

Bloco	Talhao	Variedade	Estágio de Corte	Amb. Prod.	Data Plantio	Data Último Corte	Área (ha)	Estimativas Área (ha)	Estimativas Finalid	Estimativas Produt.	Prod. Total	Dist.	Esp.	Tipo Corte	Experimento
1	37	CTC2994	3C	A	06/04/23	08/08/25	5,24	5,24	1-MO.	80,0	419,20	35	1,5	MEC.	
1	38	CTC2994	3C	A	06/04/23	08/08/25	13,21	13,21	1-MO.	80,0	1.056,80	35	1,5	MEC.	
1	39	IACSP01-5503	1C	BA	17/03/25	08/01/26	11,75	11,75	2-MU.	70,0	822,50	35	1,5	MEC.	
1	40	RB127825	1C	BA	26/02/25		1,67	1,67	1-MO.	130,0	217,10	35	1,5	MEC.	
1	41	RB127825	1C	BA	15/03/25		9,69	9,69	1-MO.	130,0	1.259,70	35	1,5	MEC.	
1	42	CTC3445	1C	A	18/03/25	05/12/25	25,69	25,69	1-MO.	110,0	2.825,90	35	1,5	MEC.	
1	43	CTC3445	2C	A	17/03/25	05/12/25	10,97	10,97	1-MO.	110,0	1.206,70	35	1,5	MEC.	
1	44	RB127825	1C	BA	15/03/25		20,03	20,03	1-MO.	130,0	2.603,90	35	1,5	MEC.	
1	45	CTC2519	FORM	BA	04/04/26		12,81	0,00	.		0,00	35	1,5	N/D	
1	46	CTC2519	FORM	A	08/04/26		8,94	0,00	.		0,00	35	1,5	N/D	
1	47	CTC2519	FORM	A	10/04/26		13,43	0,00	.		0,00	35	1,5	N/D	
1	48	CTC2519	FORM	BA	07/04/26		11,00	0,00	.		0,00	35	1,5	N/D	
1	49	CTC2519	FORM	A	02/04/26		6,95	0,00	.		0,00	35	1,5	N/D	
1	50	CTC2519	FORM	A	10/04/26		3,94	0,00	.		0,00	35	1,5	N/D	
1	51	RB985476	3C	BA	07/04/23	20/06/25	24,76	24,76	1-MO.	75,0	1.857,00	35	1,5	MEC.	
1	52	CTC9006	FORM	A	14/01/26		1,61	0,00	.		0,00	35	1,5	N/D	
1	52	IACSP01-5503	FORM	A	14/01/26		10,45	0,00	.		0,00	35	1,5	N/D	
1	52	VIVEIRO	FORM	A	14/01/26		1,68	0,00	.		0,00	35	1,5	N/D	
1	53	CTC9006	3C	B	02/04/23	18/02/26	5,27	5,27	2-MU.	45,0	237,15	35	1,5	MEC.	
1	54	CTC9006	3C	B	03/04/23	18/02/26	0,77	0,77	2-MU.	45,0	34,65	35	1,5	MEC.	
1	55	CTC9006	3C	B	02/04/23	18/02/26	12,36	9,58	2-MU.	45,0	431,10	35	1,5	MEC.	
1	55	CTC9006	3C	B	02/04/23	18/02/26	12,36	2,78	1-MO.	80,0	222,40	35	1,5	MEC.	
1	56	CTC9006	3C	B	03/04/23	18/02/26	2,39	1,58	2-MU.	45,0	71,10	35	1,5	MEC.	
1	56	CTC9006	3C	B	03/04/23	18/02/26	2,39	0,81	1-MO.	80,0	64,80	35	1,5	MEC.	
1	57	CTC4	5C	BA	01/11/21	18/07/25	14,06	14,06	1-MO.	60,0	843,60	35	1,5	MEC.	
1	57	RB966928	5C	BA	01/11/21	18/07/25	2,06	2,06	1-MO.	60,0	123,60	35	1,5	MEC.	
1	60	CTC9003	4C	B	20/04/22	22/07/25	2,25	2,25	1-MO.	68,0	153,00	35	1,5	MEC.	
1	61	CTC9003	4C	B	20/04/22	22/07/25	8,36	8,36	1-MO.	68,0	568,48	35	1,5	MEC.	
1	62	CTC9003	4C	B	19/04/22	22/07/25	5,20	5,20	1-MO.	68,0	353,60	35	1,5	MEC.	
1	63	CTC9003	4C	B	20/04/22	22/07/25	4,38	4,38	1-MO.	68,0	297,84	35	1,5	MEC.	
1	64	CTC9003	4C	BA	20/04/22	22/07/25	4,34	4,34	1-MO.	68,0	295,12	35	1,5	MEC.	
1	65	CTC9003	4C	BA	19/04/22	22/07/25	20,95	20,95	1-MO.	68,0	1.424,60	35	1,5	MEC.	
1	66	CTC9006	3C	B	03/04/23	18/02/26	2,35	2,25	1-MO.	80,0	180,00	35	1,5	MEC.	
1	66	CTC9006	3C	B	03/04/23	18/02/26	2,35	0,10	2-MU.	45,0	4,50	35	1,5	MEC.	
1	67	CTC9006	1C	BA	23/02/25	07/01/26	13,86	10,45	1-MO.	130,0	1.358,50	35	1,5	MEC.	
1	67	CTC9006	1C	BA	23/02/25	07/01/26	13,86	3,41	2-MU.	50,0	170,50	35	1,5	MEC.	
1	68	IACSP01-5503	1C	BA	24/02/25		13,86	13,86	1-MO.	130,0	1.801,80	35	1,5	MEC.	
1	69	CTC9006	1C	BA	25/02/25	07/01/26	13,56	5,52	1-MO.	90,0	496,80	35	1,5	MEC.	
1	69	CTC9006	1C	BA	25/02/25	07/01/26	13,56	8,04	2-MU.	50,0	402,00	35	1,5	MEC.	
1	69	IACSP01-5503	1C	BA	25/02/25	07/01/26	3,53	2,09	2-MU.	50,0	104,50	35	1,5	MEC.	
1	69	IACSP01-5503	1C	BA	25/02/25	07/01/26	3,53	1,44	1-MO.	90,0	129,60	35	1,5	MEC.	

Caderno de Mapas

Bloco	Talhao	Variedade	Estágio de Corte	Amb. Prod.	Data Plantio	Data Último Corte	Área (ha)	Estimativas Área (ha)	Estimativas Finalid	Estimativas Produt.	Prod. Total	Dist.	Esp.	Tipo Corte	Experimento
1	70	CTC9003	4C	BA	20/04/22	22/07/25	0,89	0,89	1-MO.	70,0	62,30	35	1,5	MEC.	
1	70	VIVEIRO	4C	BA	20/04/22	22/07/25	14,14	14,14	1-MO.	70,0	989,80	35	1,5	MEC.	
1	71	CTC9003	4C	BA	20/04/22	22/07/25	12,94	12,94	1-MO.	70,0	905,80	35	1,5	MEC.	
1	72	CTC9003	4C	BA	19/04/22	22/07/25	20,45	20,45	1-MO.	70,0	1.431,50	35	1,5	MEC.	
1	73	RB985476	3C	BA	31/03/23	22/07/25	11,35	11,35	1-MO.	90,0	1.021,50	35	1,5	MEC.	
1	74	RB985476	3C	BA	31/03/23	22/07/25	17,64	17,64	1-MO.	90,0	1.587,60	35	1,5	MEC.	
1	75	RB985476	3C	BA	31/03/23	22/07/25	22,63	22,63	1-MO.	90,0	2.036,70	35	1,5	MEC.	
1	76	RB985476	3C	BA	31/03/23	22/07/25	1,06	1,06	1-MO.	90,0	95,40	35	1,5	MEC.	
1	77	RB985476	3C	A	03/04/23	08/08/25	5,55	5,55	1-MO.	90,0	499,50	35	1,5	MEC.	
1	78	RB985476	3C	A	03/04/23	08/08/25	10,92	10,92	1-MO.	90,0	982,80	35	1,5	MEC.	
1	79	RB985476	3C	A	04/04/23	08/08/25	10,65	10,65	1-MO.	90,0	958,50	35	1,5	MEC.	
1	80	CTC9006	3C	A	03/04/23	08/08/25	3,75	3,75	1-MO.	90,0	337,50	35	1,5	MEC.	
1	80	IACCTC07-7207	3C	A	03/04/23	08/08/25	3,17	3,17	1-MO.	90,0	285,30	35	1,5	MEC.	
1	81	CTC9006	3C	A	04/04/23	08/08/25	3,03	3,03	1-MO.	90,0	272,70	35	1,5	MEC.	
1	81	IACCTC07-7207	3C	A	04/04/23	08/08/25	2,57	2,57	1-MO.	90,0	231,30	35	1,5	MEC.	
1	82	CTC9008	1C	CB	08/02/25	20/02/26	3,46	3,46	2-MU.	70,0	242,20	35	1,5	MEC.	
1	83	CTC9008	1C	CB	10/02/25	20/02/26	2,72	2,72	2-MU.	70,0	190,40	35	1,5	MEC.	
1	84	CTC9008	1C	CB	10/02/25	20/02/26	5,60	5,60	2-MU.	70,0	392,00	35	1,5	MEC.	
1	85	CTC9008	1C	CB	10/02/25	20/02/26	0,76	0,76	2-MU.	70,0	53,20	35	1,5	MEC.	
1	86	CTC9008	1C	CB	11/02/25	20/02/26	1,96	1,96	2-MU.	70,0	137,20	35	1,5	MEC.	
1	87	CTC9008	1C	CB	11/02/25	20/02/26	2,76	2,59	2-MU.	70,0	181,30	35	1,5	MEC.	
1	87	CTC9008	1C	CB	11/02/25	20/02/26	2,76	0,17	1-MO.	110,0	18,70	35	1,5	MEC.	
1	88	CTC9008	1C	A	11/02/25	20/02/26	8,64	3,78	1-MO.	110,0	415,80	35	1,5	MEC.	
1	88	CTC9008	1C	A	11/02/25	20/02/26	8,64	4,86	2-MU.	70,0	340,20	35	1,5	MEC.	
1	89	CTC9008	1C	A	12/02/25		5,12	5,12	1-MO.	110,0	563,20	35	1,5	MEC.	
1	90	CTC9008	1C	A	13/02/25		4,05	4,05	1-MO.	110,0	445,50	35	1,5	MEC.	
1	91	CTC9008	1C	A	12/02/25		0,84	0,84	1-MO.	110,0	92,40	35	1,5	MEC.	
1	110	IACSP01-5503	3C	BA	27/03/23	08/08/25	19,28	19,28	1-MO.	70,0	1.349,60	35	1,5	MEC.	
Total/Média (1 / 26 · BOA VISTA)							967,28	746,04		80,8	60.264,52				

N: 7728329.923
E: 324766.8697
LAT: −20°32'10.1052" (−20.53614034)
LONG: −46°40'52.1273" (−46.68114647)

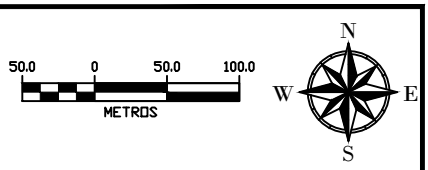

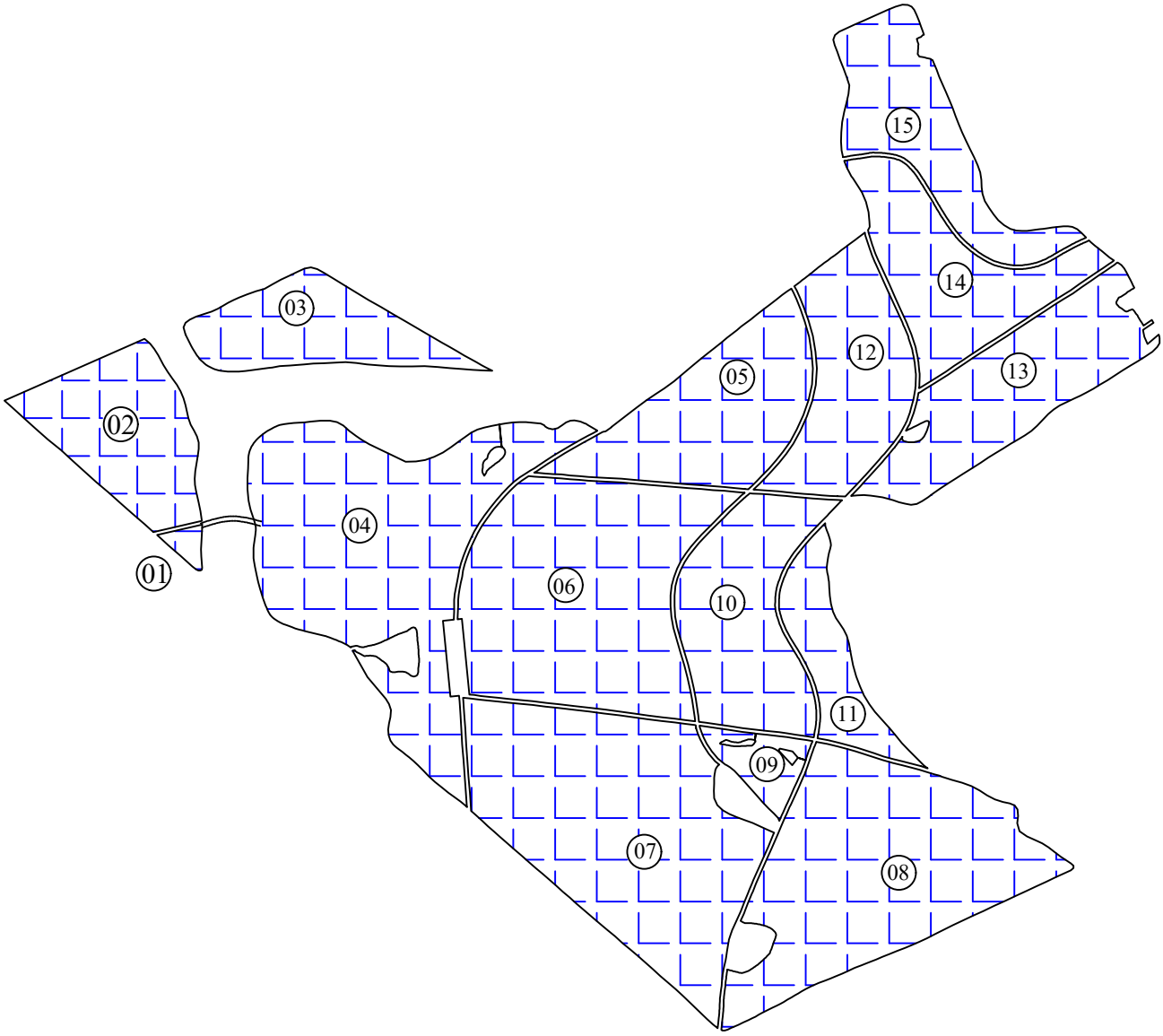

CTC - 2

TABELA DE VARIEDADE	
VARIEDADE	ÁREA
CTC2	70,24
Total Geral	**70,24**

IPIRANGA AGROINDUSTRIAL

PROJETO: CADERNO DE MAPA 25'26	DATA: 24-04-2025	ESCALA: 1:5000	TOPÓGRAFO: CRISTIAN
FAZENDA: 027 - CAETÉS	MUNICÍPIO: PASSOS - MG		ÁREA (ha): 70,24
PROPRIETÁRIO: CIA AGROPASTORIL DO RIO GRANDE	UNIDADE: IPIRANGA PASSOS - MG		CÓDIGO: 027

Caderno de Mapas

Bloco	Talhao	Variedade	Estágio de Corte	Amb. Prod.	Data Plantio	Último Corte	Área (ha)	Estimativas Área (ha)	Finalid	Produt.	Prod. Total	Dist.	Esp.	Tipo Corte	Experimento
1 · REG 1			**27 · CAETES**				**IPIRANGA AGROINDUSTRIAL S.A**								
1	1	CTC2	3C	A	23/02/23	12/09/25	0,26	0,26	1-MO.	65,0	16,90	31,2	1,5	MEC.	
1	2	CTC2	3C	A	23/02/23	12/09/25	3,58	3,58	1-MO.	65,0	232,70	31,2	1,5	MEC.	
1	3	CTC2	2C	A	29/01/25	05/12/25	3,01	3,01	2-MU.	70,0	210,70	31,2	1,5	MEC.	
1	4	CTC2	1C	A	27/01/25	30/04/26	9,56	9,56	1-MO.	115,0	1.099,40	31,2	1,5	MEC.	
1	5	CTC2	1C	B	22/01/25	30/04/26	4,47	4,47	1-MO.	130,0	581,10	31,2	1,5	MEC.	
1	6	CTC2	1C	B	23/01/25	30/04/26	8,45	8,45	1-MO.	130,0	1.098,50	31,2	1,5	MEC.	
1	7	CTC2	1C	B	24/01/25	30/04/26	9,55	9,55	1-MO.	130,0	1.241,50	31,2	1,5	MEC.	
1	8	CTC2	2C	CB	25/01/25	05/12/25	8,41	8,41	2-MU.	70,0	588,70	31,2	1,5	MEC.	
1	9	CTC2	1C	CB	23/01/25	30/04/26	0,83	0,83	1-MO.	130,0	107,90	31,2	1,5	MEC.	
1	10	CTC2	1C	CB	23/01/25	30/04/26	4,30	4,30	1-MO.	130,0	559,00	31,2	1,5	MEC.	
1	11	CTC2	2C	CB	25/01/25	05/12/25	1,91	1,91	2-MU.	70,0	133,70	31,2	1,5	MEC.	
1	12	CTC2	1C	B	25/01/25	30/04/26	3,89	3,89	1-MO.	130,0	505,70	31,2	1,5	MEC.	
1	13	CTC2	1C	B	25/01/25	30/04/26	4,51	4,51	1-MO.	115,0	518,65	31,2	1,5	MEC.	
1	14	CTC2	1C	B	25/01/25	30/04/26	3,85	2,72	2-MU.	50,0	136,00	31,2	1,5	MEC.	
1	14	CTC2	1C	B	25/01/25	30/04/26	3,85	1,13	1-MO.	93,0	105,09	31,2	1,5	MEC.	
1	15	CTC2	1C	B	29/01/25	30/04/26	3,66	1,10	2-MU.	50,0	55,00	31,2	1,5	MEC.	
1	15	CTC2	1C	B	29/01/25	30/04/26	3,66	2,56	1-MO.	93,0	238,08	31,2	1,5	MEC.	
Total/Média (1 / 27 · CAETES)							70,24	70,24		105,8	7.428,62				

N: 7719689.140
E: 320707.2671
LAT: -20°36'49.6873" (-20.61380203)
LONG: -46°43'15.4067" (-46.72094630)

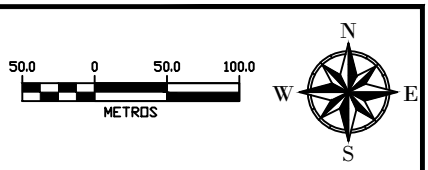

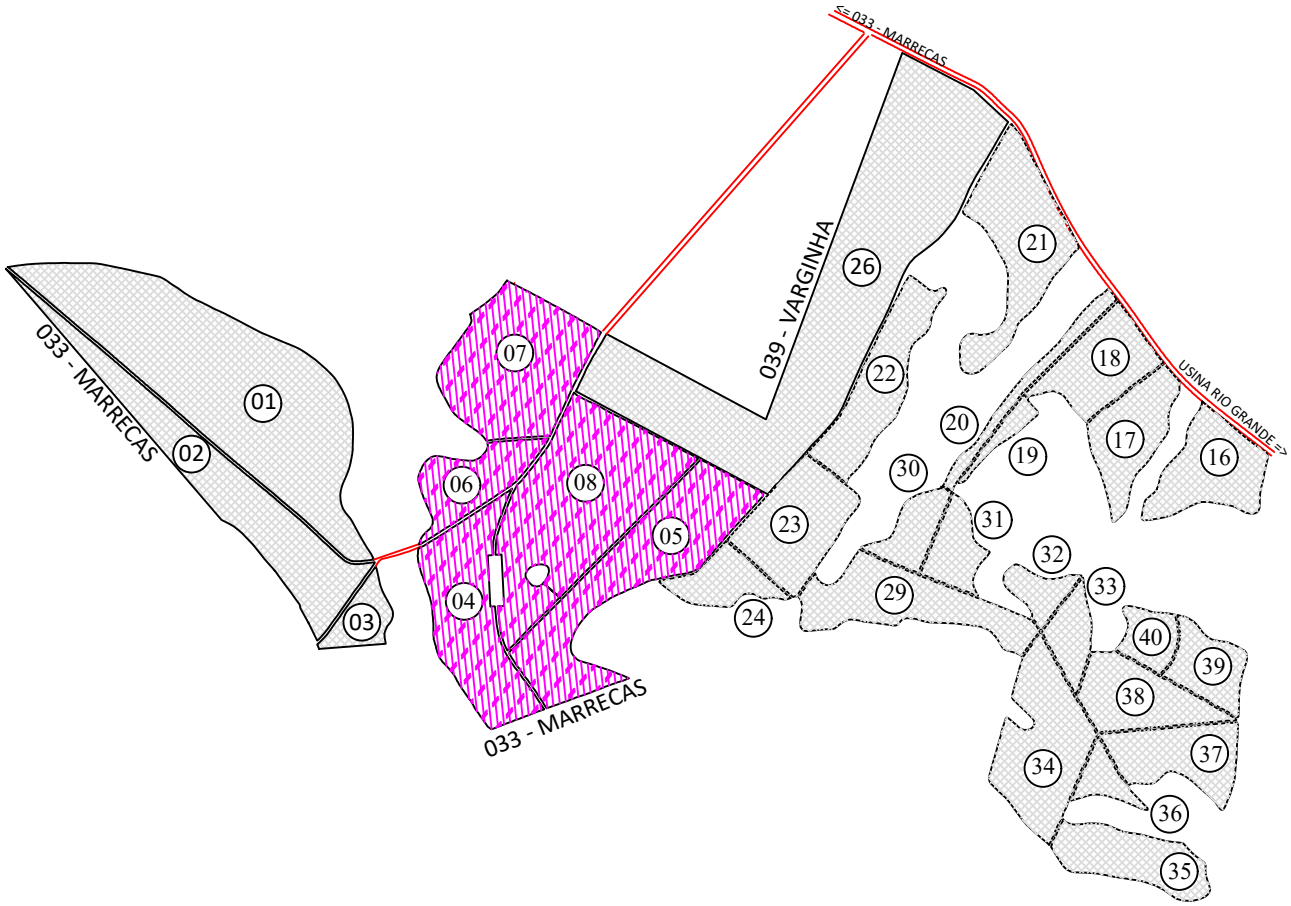

CTC - 4
CTC -2994

TABELA DE VARIEDADE	
VARIEDADE	ÁREA
CTC2994	36,53
CTC4	111,31
Total Geral	**147,84**

IPIRANGA AGROINDUSTRIAL

PROJETO: CADERNO DE MAPA 26'27	DATA: 25/05/2026	ESCALA: 1:5000	TOPÓGRAFO: CRISTIAN
FAZENDA: 028 - CANOAS	MUNICÍPIO: PASSOS - MG		ÁREA (ha): 147,84
PROPRIETÁRIO: CIA AGROPASTORIL DO RIO GRANDE	UNIDADE: IPIRANGA PASSOS - MG		CÓDIGO: 028

Caderno de Mapas

Bloco	Talhao	Variedade	Estágio de Corte	Amb. Prod.	Data Plantio	Último Corte	Área (ha)	Estimativas Área (ha)	Finalid	Produt.	Prod. Total	Dist.	Esp.	Tipo Corte	Experimento
1 · REG 1			**28 · CANOAS**				**IPIRANGA AGROINDUSTRIAL S.A**								
1	1	CTC4	4C	A	26/03/22	09/10/25	18,23	18,23	1-MO.	73,0	1.330,79	33,7	1,5	MEC.	
1	2	CTC4	4C	A	26/03/22	09/10/25	8,10	8,10	1-MO.	73,0	591,30	33,7	1,5	MEC.	
1	3	CTC4	4C	A	27/03/22	09/10/25	1,44	1,44	1-MO.	73,0	105,12	33,7	1,5	MEC.	
1	4	CTC2994	FORM	CB	22/02/26		6,35	0,00	.		0,00	33,7	1,5	N/D	
1	5	CTC2994	FORM	CB	21/02/26		8,30	0,00	.		0,00	33,7	1,5	N/D	
1	6	CTC2994	FORM	CB	22/02/26		2,92	0,00	.		0,00	33,7	1,5	N/D	
1	7	CTC2994	FORM	CB	20/02/26		7,90	0,00	.		0,00	33,7	1,5	N/D	
1	8	CTC2994	FORM	CB	20/02/26		11,06	0,00	.		0,00	33,7	1,5	N/D	
1	16	CTC4	3C	BA	02/03/23	17/04/25	3,86	3,86	1-MO.	80,0	308,80	33,7	1,5	MEC.	
1	17	CTC4	3C	CB	02/03/23	17/04/25	3,33	3,33	1-MO.	80,0	266,40	33,7	1,5	MEC.	
1	18	CTC4	3C	A	02/03/23	17/04/25	3,45	3,45	1-MO.	80,0	276,00	33,7	1,5	MEC.	
1	19	CTC4	3C	CB	02/03/23	17/04/25	0,59	0,59	1-MO.	80,0	47,20	33,7	1,5	MEC.	
1	20	CTC4	3C	A	02/03/23	17/04/25	1,32	1,32	1-MO.	80,0	105,60	33,7	1,5	MEC.	
1	21	CTC4	3C	A	01/03/23	17/04/25	5,96	5,96	1-MO.	80,0	476,80	33,7	1,5	MEC.	
1	22	CTC4	3C	A	01/03/23	17/04/25	4,32	4,32	1-MO.	80,0	345,60	33,7	1,5	MEC.	
1	23	CTC4	3C	CB	01/03/23	17/04/25	4,53	4,53	1-MO.	80,0	362,40	33,7	1,5	MEC.	
1	24	CTC4	3C	CB	01/03/23	17/04/25	1,87	1,87	1-MO.	80,0	149,60	33,7	1,5	MEC.	
1	26	CTC4	5C	A	28/03/21	09/10/25	23,33	23,33	1-MO.	55,0	1.283,15	33,7	1,5	MEC.	
1	29	CTC4	3C	CB	02/03/23	17/04/25	4,97	4,97	1-MO.	80,0	397,60	33,7	1,5	MEC.	
1	30	CTC4	3C	CB	02/03/23	17/04/25	1,58	1,58	1-MO.	80,0	126,40	33,7	1,5	MEC.	
1	31	CTC4	3C	CB	02/03/23	17/04/25	1,67	1,67	1-MO.	80,0	133,60	33,7	1,5	MEC.	
1	32	CTC4	3C	CB	03/03/23	17/04/25	1,08	1,08	1-MO.	80,0	86,40	33,7	1,5	MEC.	
1	33	CTC4	3C	CB	02/03/23	17/04/25	1,43	1,43	1-MO.	80,0	114,40	33,7	1,5	MEC.	
1	34	CTC4	3C	CB	11/03/23	17/04/25	5,65	5,65	1-MO.	80,0	452,00	33,7	1,5	MEC.	
1	35	CTC4	3C	A	03/03/23	17/04/25	3,43	3,43	1-MO.	80,0	274,40	33,7	1,5	MEC.	
1	36	CTC4	3C	CB	20/03/23	17/04/25	0,93	0,93	1-MO.	80,0	74,40	33,7	1,5	MEC.	
1	37	CTC4	3C	CB	11/03/23	17/04/25	3,38	3,38	1-MO.	80,0	270,40	33,7	1,5	MEC.	
1	38	CTC4	3C	CB	11/03/23	17/04/25	3,39	3,39	1-MO.	80,0	271,20	33,7	1,5	MEC.	
1	39	CTC4	3C	CB	03/03/23	17/04/25	2,14	2,14	1-MO.	80,0	171,20	33,7	1,5	MEC.	
1	40	CTC4	3C	CB	03/03/23	17/04/25	1,33	1,33	1-MO.	80,0	106,40	33,7	1,5	MEC.	
Total/Média (1 / 28 · CANOAS)							147,84	111,31		73,0	8.127,16				

N: 7729865.353
E: 321716.5961
LAT: −20°31'19.1498" (−20.52198606)
LONG: −46°42'36.8626" (−46.71023961)

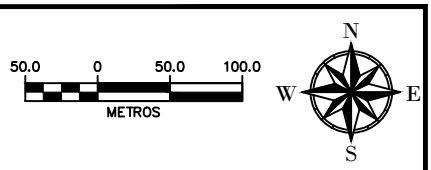

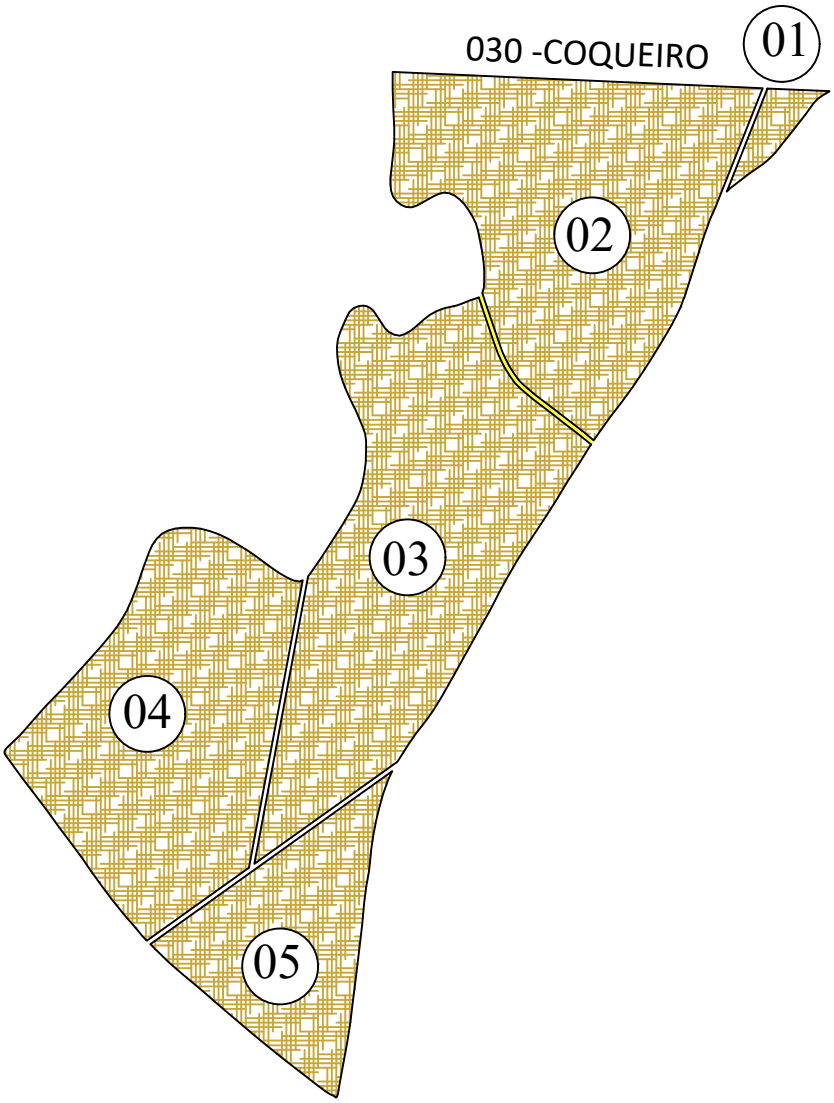

IACSP 95-5094

TABELA DE VARIEDADE	
VARIEDADE	ÁREA
IACSP95-5094	30,51
Total Geral	**30,51**

IPIRANGA AGROINDUSTRIAL	PROJETO: CADERNO DE MAPA 26'27	DATA: 21/01/2026	ESCALA: 1:5000	TOPÓGRAFO: CRISTIAN
	FAZENDA: 029 - COQUEIRINHO	MUNICÍPIO: PASSOS MG		ÁREA (ha): 30,51
	PROPRIETÁRIO: AGRO PASTORIL	UNIDADE: IPIRANGA PASSOS		ÁREA (ha): 029

Caderno de Mapas

Bloco	Talhao	Variedade	Estágio de Corte	Amb. Prod.	Data Plantio	Data Último Corte	Área (ha)	Estimativas Área (ha)	Estimativas Finalid	Estimativas Produt.	Prod. Total	Dist.	Esp.	Tipo Corte	Experimento
1 · REG 1			**29 · COQUEIRINHO**				**IPIRANGA AGROINDUSTRIAL S.A**								
1	1	IACSP95-5094	4C	A	21/02/22	18/08/25	0,39	0,39	1-MO.	63,0	24,57	31,2	1,5	MEC.	
1	2	IACSP95-5094	4C	A	21/02/22	18/08/25	8,90	8,90	1-MO.	63,0	560,70	31,2	1,5	MEC.	
1	3	IACSP95-5094	4C	A	21/02/22	18/08/25	9,54	9,54	1-MO.	63,0	601,02	31,2	1,5	MEC.	
1	4	IACSP95-5094	4C	A	21/02/22	18/08/25	7,88	7,88	1-MO.	63,0	496,44	31,2	1,5	MEC.	
1	5	IACSP95-5094	4C	A	21/02/22	18/08/25	3,80	3,80	1-MO.	63,0	239,40	31,2	1,5	MEC.	
Total/Média (1 / 29 · COQUEIRINHO)							30,51	30,51		63,0	1.922,13				

N: 7729865.353
E: 321716.5961
LAT: −20°31'19.1498" (−20.52198606)
LONG: −46°42'36.8626" (−46.71023961)

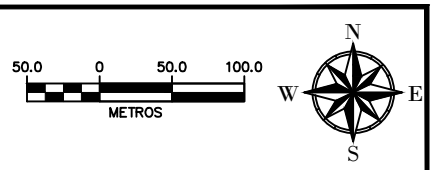

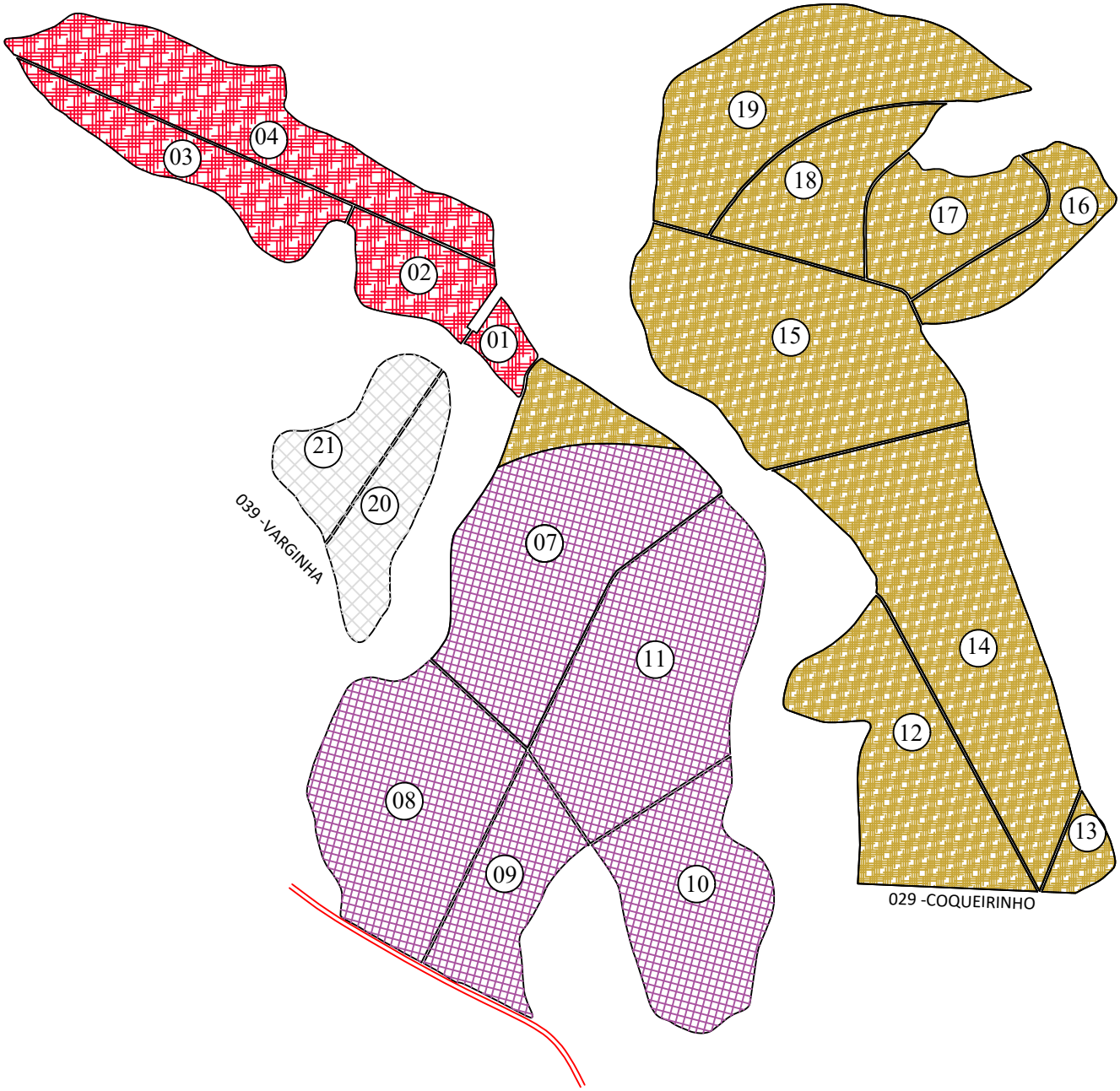

CTC - 4
IACSP 95-5094
IAC CTC 07-8008
IAC SP 01-5503

TABELA DE VARIEDADE

VARIEDADE	ÁREA
CTC4	11,91
IACCTC07-8008	83,15
IACSP01-5503	28,88
IACSP95-5094	109,93
Total Geral	**233,87**

IPIRANGA AGROINDUSTRIAL

PROJETO: CADERNO DE MAPA 26'27	DATA: 21/01/2026	ESCALA: 1:5000	TOPÓGRAFO: CRISTIAN
FAZENDA: 030 - COQUEIRO	MUNICÍPIO: PASSOS MG		ÁREA (ha): 233,87
PROPRIETÁRIO: AGRO PASTORIL	UNIDADE: IPIRANGA PASSOS		ÁREA (ha): 030

Caderno de Mapas

Bloco	Talhao	Variedade	Estágio de Corte	Amb. Prod.	Data Plantio	Data Último Corte	Área (ha)	Estimativas Área (ha)	Estimativas Finalid	Estimativas Produt.	Prod. Total	Dist.	Esp.	Tipo Corte	Experimento
1 · REG 1			**30 · COQUEIROS**				**IPIRANGA AGROINDUSTRIAL S.A**								
1	1	IACSP01-5503	3C	A	25/03/23	02/04/26	1,57	1,57	1-MO.	80,0	125,60	33,6	1,5	MEC.	
1	2	IACSP01-5503	3C	A	22/03/23	30/03/26	5,10	5,10	2-MU.	50,0	255,00	33,6	1,5	MEC.	
1	3	IACSP01-5503	3C	A	23/03/23	30/03/26	7,65	7,65	2-MU.	50,0	382,50	33,6	1,5	MEC.	
1	4	IACSP01-5503	3C	A	24/03/23	02/04/26	14,56	12,56	2-MU.	50,0	628,00	33,6	1,5	MEC.	
1	4	IACSP01-5503	3C	A	24/03/23	02/04/26	14,56	2,00	1-MO.	80,0	160,00	33,6	1,5	MEC.	
1	7	IACCTC07-8008	4C	A	01/03/22	22/08/25	20,64	20,64	1-MO.	68,0	1.403,52	33,6	1,5	MEC.	
1	7	IACSP95-5094	4C	A	01/03/22	22/08/25	3,90	3,90	1-MO.	68,0	265,20	33,6	1,5	MEC.	
1	8	IACCTC07-8008	4C	A	26/02/22	22/08/25	18,93	18,93	1-MO.	68,0	1.287,24	33,6	1,5	MEC.	
1	9	IACCTC07-8008	4C	A	26/02/22	22/08/25	8,40	8,40	1-MO.	68,0	571,20	33,6	1,5	MEC.	
1	10	IACCTC07-8008	4C	A	28/02/22	22/08/25	13,66	13,66	1-MO.	68,0	928,88	33,6	1,5	MEC.	
1	11	IACCTC07-8008	4C	A	27/02/22	22/08/25	21,52	21,52	1-MO.	68,0	1.463,36	33,6	1,5	MEC.	
1	12	IACSP95-5094	4C	A	25/02/22	18/08/25	15,47	15,47	1-MO.	68,0	1.051,96	33,6	1,5	MEC.	
1	13	IACSP95-5094	4C	A	22/02/22	18/08/25	1,87	1,87	1-MO.	68,0	127,16	33,6	1,5	MEC.	
1	14	IACSP95-5094	4C	A	22/02/22	18/08/25	24,35	24,35	1-MO.	68,0	1.655,80	33,6	1,5	MEC.	
1	15	IACSP95-5094	4C	A	25/02/22	18/08/25	23,73	23,73	1-MO.	68,0	1.613,64	33,6	1,5	MEC.	
1	16	IACSP95-5094	4C	A	24/02/22	18/08/25	5,95	5,95	1-MO.	68,0	404,60	33,6	1,5	MEC.	
1	17	IACSP95-5094	4C	A	24/02/22	18/08/25	7,71	7,71	1-MO.	68,0	524,28	33,6	1,5	MEC.	
1	18	IACSP95-5094	4C	A	24/02/22	18/08/25	8,79	8,79	1-MO.	68,0	597,72	33,6	1,5	MEC.	
1	19	IACSP95-5094	4C	A	25/02/22	18/08/25	18,16	18,16	1-MO.	68,0	1.234,88	33,6	1,5	MEC.	
1	20	CTC4	3C	A	14/02/23	02/04/26	6,11	6,11	1-MO.	72,0	439,92	33,6	1,5	MEC.	
1	21	CTC4	3C	A	21/02/23	02/04/26	5,80	5,80	1-MO.	72,0	417,60	33,6	1,5	MEC.	
Total/Média (1 / 30 · COQUEIROS)							233,87	233,87		66,4	15.538,06				

N: 7726579.612
E: 322044.1344
LAT: −20°33'6.0990" (−20.55169416)
LONG: −46°42'26.7436" (−46.70742877)

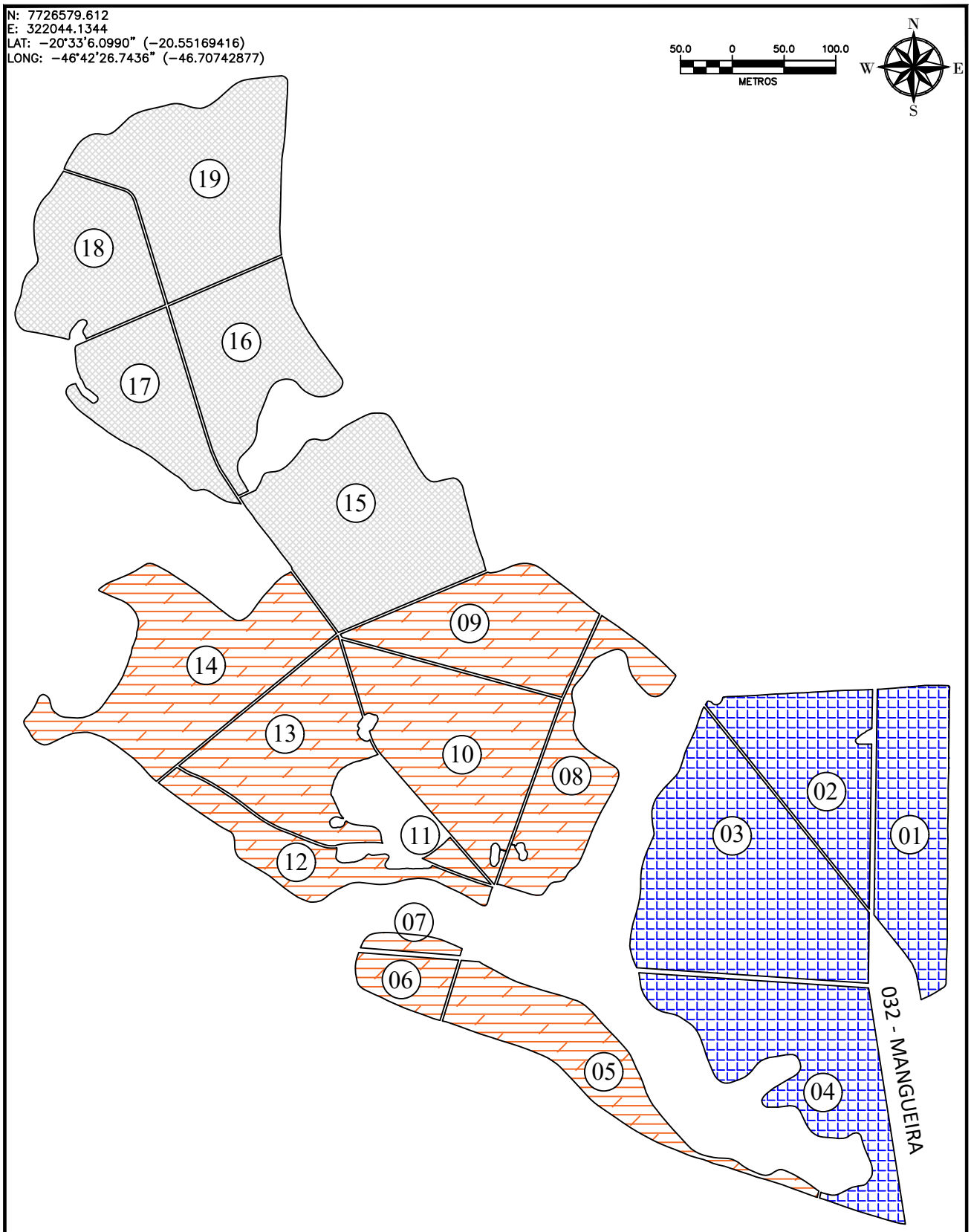

CTC - 4
CTC - 2
CTC - 9001

TABELA DE VARIEDADE	
VARIEDADE	ÁREA
CTC2	45,86
CTC4	48,34
CTC9001	61,80
Total Geral	**156,00**

IPIRANGA AGROINDUSTRIAL

PROJETO: CADERNO DE MAPA 26'27	DATA: 22/01/2026	ESCALA: 1:5000	TOPÓGRAFO: CRISTIAN
FAZENDA: 031 - ESTÂNCIA	MUNICÍPIO: PASSOS MG		ÁREA (ha): 156,00
PROPRIETÁRIO: CIA AÇUCAREIRA RIO GRANDE	UNIDADE: IPIRANGA PASSOS		CÓDIGO: 044

Caderno de Mapas

Bloco	Talhao	Variedade	Estágio de Corte	Amb. Prod.	Data Plantio	Último Corte	Área (ha)	Estimativas Área (ha)	Finalid	Produt.	Prod. Total	Dist.	Esp.	Tipo Corte	Experimento
1 · REG 1			**31 · ESTANCIA**				**IPIRANGA AGROINDUSTRIAL S.A**								
1	1	CTC2	4C	A	26/04/22	31/10/25	8,69	8,69	1-MO.	75,0	651,75	31	1,5	MEC.	
1	2	CTC2	4C	A	26/04/22	31/10/25	8,09	8,09	1-MO.	72,0	582,48	31	1,5	MEC.	
1	3	CTC2	4C	A	26/04/22	31/10/25	17,43	17,43	1-MO.	72,0	1.254,96	31	1,5	MEC.	
1	4	CTC2	4C	A	26/04/22	31/10/25	11,65	11,65	1-MO.	72,0	838,80	31	1,5	MEC.	
1	5	CTC9001	4C	A	25/04/22	31/10/25	6,96	6,96	1-MO.	64,0	445,44	31	1,5	MEC.	
1	6	CTC9001	4C	A	25/04/22	31/10/25	2,01	2,01	1-MO.	64,0	128,64	31	1,5	MEC.	
1	7	CTC9001	4C	A	24/04/22	31/10/25	0,64	0,64	1-MO.	64,0	40,96	31	1,5	MEC.	
1	8	CTC9001	4C	A	23/04/22	31/10/25	6,22	6,22	1-MO.	64,0	398,08	31	1,5	MEC.	
1	9	CTC9001	4C	A	22/04/22	31/10/25	8,11	8,11	1-MO.	64,0	519,04	31	1,5	MEC.	
1	10	CTC9001	4C	A	25/04/22	31/10/25	11,30	11,30	1-MO.	64,0	723,20	31	1,5	MEC.	
1	11	CTC9001	4C	A	25/04/22	31/10/25	0,47	0,47	1-MO.	64,0	30,08	31	1,5	MEC.	
1	12	CTC9001	4C	A	23/04/22	31/10/25	4,56	4,56	1-MO.	64,0	291,84	31	1,5	MEC.	
1	13	CTC9001	4C	CB	22/04/22	31/10/25	8,84	8,84	1-MO.	64,0	565,76	31	1,5	MEC.	
1	14	CTC9001	4C	CB	30/03/22	31/10/25	12,69	12,69	1-MO.	64,0	812,16	31	1,5	MEC.	
1	15	CTC4	4C	A	26/04/22	31/10/25	13,48	13,48	1-MO.	70,0	943,60	31	1,5	MEC.	
1	16	CTC4	4C	A	31/03/22	31/10/25	8,12	8,12	1-MO.	70,0	568,40	31	1,5	MEC.	
1	17	CTC4	4C	A	26/04/22	31/10/25	6,62	6,62	1-MO.	70,0	463,40	31	1,5	MEC.	
1	18	CTC4	4C	A	26/04/22	31/10/25	7,40	7,40	1-MO.	70,0	518,00	31	1,5	MEC.	
1	19	CTC4	4C	A	01/04/22	31/10/25	12,72	12,72	1-MO.	70,0	890,40	31	1,5	MEC.	
Total/Média (1 / 31 · ESTANCIA)							156,00	156,00		68,4	10.666,99				

N: 7729865.353
E: 321716.5961
LAT: −20°31'19.1498" (−20.52198606)
LONG: −46°42'36.8626" (−46.71023961)

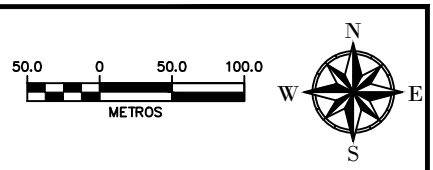

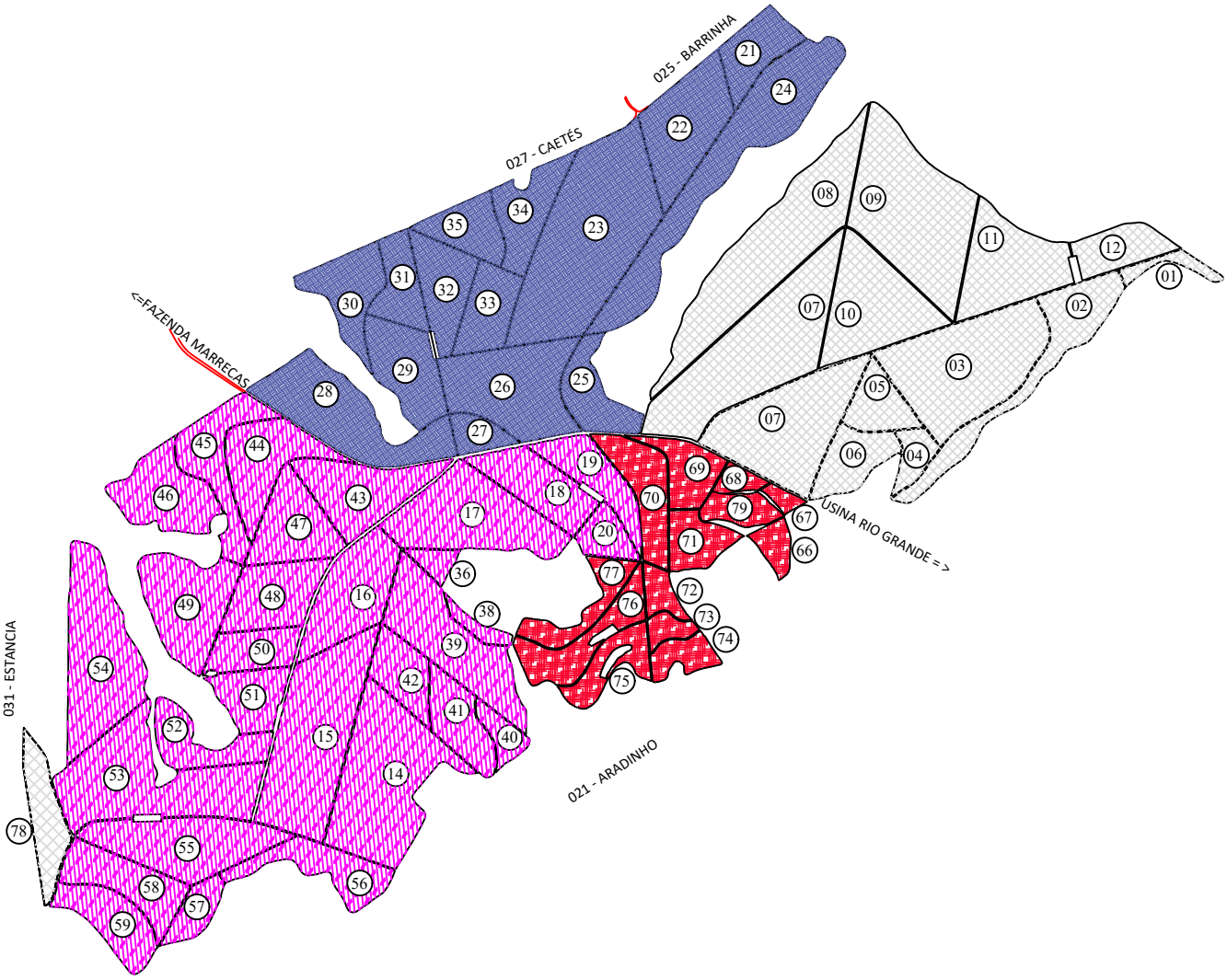

TABELA DE VARIEDADE	
VARIEDADE	ÁREA
CTC2994	229,91
CTC4	145,26
CTC9003	128,83
IACSP01-5503	40,07
Total Geral	**544,07**

- CTC - 4
- CTC - 2994
- CTC - 9003
- IAC SP 01-5503

IPIRANGA AGROINDUSTRIAL

PROJETO: CADERNO DE MAPA 26'27	DATA: 22/01/2026	ESCALA: 1:5000	TOPÓGRAFO: CRISTIAN
FAZENDA: 032 - MANGUEIRA	MUNICÍPIO: PASSOS MG		ÁREA (ha): 544,07
PROPRIETÁRIO: CIA AÇUCAREIRA RIO GRANDE	UNIDADE: IPIRANGA PASSOS		CÓDIGO: 032

Caderno de Mapas

Bloco	Talhao	Variedade	Estágio de Corte	Amb. Prod.	Data Plantio	Último Corte	Área (ha)	Estimativas Área (ha)	Finalid	Produt.	Prod. Total	Dist.	Esp.	Tipo Corte	Experimento
1 · REG 1			32 · MANGUEIRA				IPIRANGA AGROINDUSTRIAL S.A								
1	1	CTC4	4C	B	02/04/22	26/11/25	1,44	1,44	1-MO.	60,0	86,40	27	1,5	MEC.	
1	2	CTC4	4C	A	07/04/22	26/11/25	9,45	9,45	1-MO.	60,0	567,00	27	1,5	MEC.	
1	3	CTC4	4C	A	07/04/22	26/11/25	17,59	17,59	1-MO.	60,0	1.055,40	27	1,5	MEC.	
1	4	CTC4	4C	A	07/04/22	26/11/25	2,17	2,17	1-MO.	60,0	130,20	27	1,5	MEC.	
1	5	CTC4	4C	A	08/04/22	26/11/25	4,04	4,04	1-MO.	60,0	242,40	27	1,5	MEC.	
1	6	CTC4	4C	A	08/04/22	26/11/25	4,84	4,84	1-MO.	60,0	290,40	27	1,5	MEC.	
1	7	CTC4	4C	A	18/10/22	26/11/25	19,93	19,93	1-MO.	60,0	1.195,80	27	1,5	MEC.	
1	8	CTC4	4C	A	17/10/22	26/11/25	19,54	19,54	1-MO.	60,0	1.172,40	27	1,5	MEC.	
1	9	CTC4	4C	A	15/10/22	26/11/25	19,63	19,63	1-MO.	60,0	1.177,80	27	1,5	MEC.	
1	10	CTC4	4C	B	14/10/22	26/11/25	11,66	11,66	1-MO.	60,0	699,60	27	1,5	MEC.	
1	11	CTC4	4C	B	14/10/22	26/11/25	10,39	10,39	1-MO.	60,0	623,40	27	1,5	MEC.	
1	12	CTC4	4C	B	11/10/22	26/11/25	4,52	4,52	1-MO.	60,0	271,20	27	1,5	MEC.	
1	13	CTC4	4C	A	01/04/22	26/11/25	14,85	14,85	1-MO.	60,0	891,00	27	1,5	MEC.	
1	14	CTC2994	2C	A	12/12/23	13/05/25	17,53	17,53	1-MO.	110,0	1.928,30	27	1,5	MEC.	
1	15	CTC2994	2C	A	27/11/23	13/05/25	17,84	17,84	1-MO.	110,0	1.962,40	27	1,5	MEC.	
1	16	CTC2994	2C	A	03/12/23	13/05/25	9,07	9,07	1-MO.	110,0	997,70	27	1,5	MEC.	
1	17	CTC2994	2C	B	26/11/23	13/05/25	13,05	13,05	1-MO.	110,0	1.435,50	27	1,5	MEC.	
1	18	CTC2994	2C	B	25/11/23	13/05/25	6,69	6,69	1-MO.	110,0	735,90	27	1,5	MEC.	
1	19	CTC2994	2C	B	26/11/23	13/05/25	5,25	5,25	1-MO.	110,0	577,50	27	1,5	MEC.	
1	20	CTC2994	2C	A	25/11/23	13/05/25	2,71	2,71	1-MO.	110,0	298,10	27	1,5	MEC.	
1	21	CTC9003	3C	BA	27/11/22	05/09/25	4,99	4,99	1-MO.	65,0	324,35	27	1,5	MEC.	
1	22	CTC9003	3C	BA	28/11/22	05/09/25	10,03	10,03	1-MO.	65,0	651,95	27	1,5	MEC.	
1	23	CTC9003	3C	BA	29/11/22	05/09/25	24,36	24,36	1-MO.	65,0	1.583,40	27	1,5	MEC.	
1	24	CTC9003	3C	BA	26/11/22	05/09/25	17,30	17,30	1-MO.	65,0	1.124,50	27	1,5	MEC.	
1	25	CTC9003	3C	DC	30/11/22	05/09/25	5,05	5,05	1-MO.	65,0	328,25	27	1,5	MEC.	
1	26	CTC9003	3C	DC	02/12/22	05/09/25	12,63	12,63	1-MO.	65,0	820,95	27	1,5	MEC.	
1	27	CTC9003	3C	DC	03/12/22	05/09/25	2,23	2,23	1-MO.	65,0	144,95	27	1,5	MEC.	
1	28	CTC9003	3C	A	10/12/22	05/09/25	12,79	12,79	1-MO.	65,0	831,35	27	1,5	MEC.	
1	29	CTC9003	3C	DC	03/12/22	05/09/25	7,25	7,25	1-MO.	65,0	471,25	27	1,5	MEC.	
1	30	CTC9003	4C	A	01/12/22	05/09/25	6,21	6,21	1-MO.	65,0	403,65	27	1,5	MEC.	
1	31	CTC9003	3C	DC	02/12/22	05/09/25	4,43	4,43	1-MO.	65,0	287,95	27	1,5	MEC.	
1	32	CTC9003	3C	DC	09/12/22	05/09/25	6,00	6,00	1-MO.	65,0	390,00	27	1,5	MEC.	
1	33	CTC9003	3C	DC	05/12/22	05/09/25	5,15	5,15	1-MO.	65,0	334,75	27	1,5	MEC.	
1	34	CTC9003	3C	CB	05/12/22	05/09/25	5,84	5,84	1-MO.	65,0	379,60	27	1,5	MEC.	
1	35	CTC9003	3C	A	10/12/22	05/09/25	4,57	4,57	1-MO.	65,0	297,05	27	1,5	MEC.	
1	36	CTC2994	2C	A	11/01/24	13/05/25	1,32	1,32	1-MO.	95,0	125,40	27	1,5	MEC.	
1	38	CTC2994	2C	A	15/01/24	13/05/25	1,22	1,22	1-MO.	95,0	115,90	27	1,5	MEC.	
1	39	CTC2994	3C	A	13/01/24	13/05/25	11,55	11,55	1-MO.	95,0	1.097,25	27	1,5	MEC.	
1	40	CTC2994	3C	A	13/01/24	13/05/25	2,00	2,00	1-MO.	95,0	190,00	27	1,5	MEC.	

Caderno de Mapas

Bloco	Talhao	Variedade	Estágio de Corte	Amb. Prod.	Data Plantio	Data Último Corte	Área (ha)	Estimativas Área (ha)	Estimativas Finalid	Estimativas Produt.	Prod. Total	Dist.	Esp.	Tipo Corte	Experimento
1	41	CTC2994	2C	A	12/01/24	13/05/25	5,21	5,21	1-MO.	95,0	494,95	27	1,5	MEC.	
1	42	CTC2994	2C	A	12/01/24	13/05/25	4,47	4,47	1-MO.	95,0	424,65	27	1,5	MEC.	
1	43	CTC2994	3C	B	08/02/23	17/10/25	8,44	8,44	1-MO.	95,0	801,80	27	1,5	MEC.	
1	44	CTC2994	3C	B	11/02/23	17/10/25	7,68	7,68	1-MO.	95,0	729,60	27	1,5	MEC.	
1	45	CTC2994	3C	B	10/02/23	17/10/25	7,17	7,17	1-MO.	95,0	681,15	27	1,5	MEC.	
1	46	CTC2994	4C	B	07/03/23	17/10/25	7,89	7,89	1-MO.	95,0	749,55	27	1,5	MEC.	
1	47	CTC2994	3C	B	27/02/23	17/10/25	7,07	7,07	1-MO.	95,0	671,65	27	1,5	MEC.	
1	48	CTC2994	3C	B	28/02/23	17/10/25	6,94	6,94	1-MO.	95,0	659,30	27	1,5	MEC.	
1	49	CTC2994	3C	A	05/03/23	17/10/25	9,96	9,96	1-MO.	95,0	946,20	27	1,5	MEC.	
1	50	CTC2994	3C	B	28/02/23	17/10/25	4,23	4,23	1-MO.	95,0	401,85	27	1,5	MEC.	
1	51	CTC2994	3C	B	13/03/23	17/10/25	4,62	4,62	1-MO.	95,0	438,90	27	1,5	MEC.	
1	52	CTC2994	3C	B	09/02/23	17/10/25	5,13	5,13	1-MO.	95,0	487,35	27	1,5	MEC.	
1	53	CTC2994	3C	B	22/02/23	17/10/25	16,57	16,57	1-MO.	95,0	1.574,15	27	1,5	MEC.	
1	54	CTC2994	4C	A	26/02/23	17/10/25	14,29	14,29	1-MO.	95,0	1.357,55	27	1,5	MEC.	
1	55	CTC2994	3C	A	01/03/23	17/10/25	10,92	10,92	1-MO.	95,0	1.037,40	27	1,5	MEC.	
1	56	CTC2994	3C	A	02/03/23	17/10/25	6,00	6,00	1-MO.	95,0	570,00	27	1,5	MEC.	
1	57	CTC2994	3C	A	02/03/23	17/10/25	2,71	2,71	1-MO.	95,0	257,45	27	1,5	MEC.	
1	58	CTC2994	3C	B	01/03/23	17/10/25	6,60	6,60	1-MO.	95,0	627,00	27	1,5	MEC.	
1	59	CTC2994	3C	B	06/03/23	17/10/25	5,78	5,78	1-MO.	95,0	549,10	27	1,5	MEC.	
1	66	IACSP01-5503	3C	A	24/02/23	21/11/25	1,88	1,88	1-MO.	78,0	146,64	27	1,5	MEC.	
1	67	IACSP01-5503	3C	A	24/02/23	21/11/25	0,80	0,80	1-MO.	78,0	62,40	27	1,5	MEC.	
1	68	IACSP01-5503	3C	A	23/02/23	21/11/25	1,35	1,35	1-MO.	78,0	105,30	27	1,5	MEC.	
1	69	IACSP01-5503	3C	A	23/02/23	21/11/25	4,28	4,28	1-MO.	78,0	333,84	27	1,5	MEC.	
1	70	IACSP01-5503	3C	A	22/02/23	21/11/25	6,03	6,03	1-MO.	78,0	470,34	27	1,5	MEC.	
1	71	IACSP01-5503	3C	A	23/02/23	21/11/25	3,84	3,84	1-MO.	78,0	299,52	27	1,5	MEC.	
1	72	IACSP01-5503	3C	A	10/03/23	21/11/25	1,86	1,86	1-MO.	78,0	145,08	27	1,5	MEC.	
1	73	IACSP01-5503	3C	A	10/03/23	21/11/25	1,42	1,42	1-MO.	78,0	110,76	27	1,5	MEC.	
1	74	IACSP01-5503	3C	A	06/03/23	21/11/25	2,57	2,57	1-MO.	78,0	200,46	27	1,5	MEC.	
1	75	IACSP01-5503	3C	A	08/03/23	21/11/25	3,77	3,77	1-MO.	78,0	294,06	27	1,5	MEC.	
1	76	IACSP01-5503	3C	A	06/03/23	21/11/25	5,72	5,72	1-MO.	78,0	446,16	27	1,5	MEC.	
1	77	IACSP01-5503	3C	A	01/03/23	21/11/25	3,87	3,87	1-MO.	78,0	301,86	27	1,5	MEC.	
1	78	CTC4	4C	B	08/04/22	17/10/25	5,21	5,21	1-MO.	68,0	354,28	27	1,5	MEC.	
1	79	IACSP01-5503	2C	A	18/10/24	21/11/25	2,68	2,68	1-MO.	90,0	241,20	27	1,5	MEC.	
Total/Média (1 / 32 · MANGUEIRA)							544,07	544,07		79,4	43.212,40				

N: 7728460.142
E: 319170.7391
LAT: −20°32'3.9678" (−20.53443550)
LONG: −46°44'5.2471" (−46.73479085)

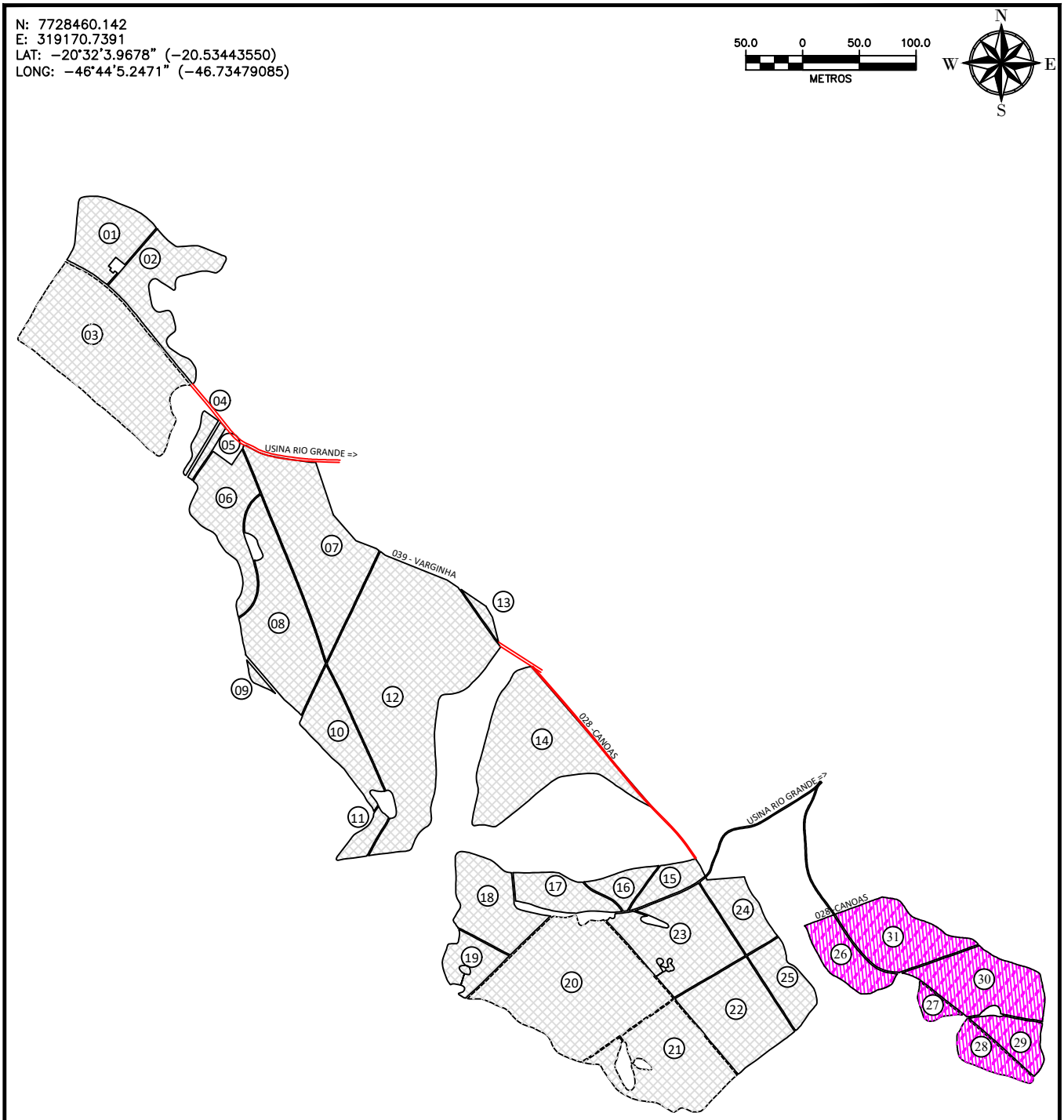

CTC - 4

CTC -2994

TABELA DE VARIEDADE	
VARIEDADE	ÁREA
CTC2994	30,48
CTC4	238,13
Total Geral	**268,61**

IPIRANGA AGROINDUSTRIAL	PROJETO: CADERNO DE MAPA 26'27	DATA: 22/01/2026	ESCALA: 1:5000	TOPÓGRAFO: CRISTIAN
	FAZENDA: 033 - MARRECAS	MUNICÍPIO: PASSOS MG		ÁREA (ha): 268,61
	PROPRIETÁRIO: CIA AÇUCAREIRA RIO GRANDA	UNIDADE: IPIRANGA PASSOS		CÓDIGO: 033

Caderno de Mapas

Bloco	Talhao	Variedade	Estágio de Corte	Amb. Prod.	Data Plantio	Último Corte	Área (ha)	Estimativas Área (ha)	Finalid	Produt.	Prod. Total	Dist.	Esp.	Tipo Corte	Experimento
1 · REG 1			**33 · MARRECAS**				**IPIRANGA AGROINDUSTRIAL S.A**								
1	1	CTC4	4C	A	19/03/22	18/09/25	6,98	6,98	1-MO.	74,0	516,52	36,2	1,5	MEC.	
1	2	CTC4	4C	A	20/03/22	18/09/25	8,25	8,25	1-MO.	74,0	610,50	36,2	1,5	MEC.	
1	3	CTC4	4C	BA	19/03/22	18/09/25	23,43	23,43	1-MO.	74,0	1.733,82	36,2	1,5	MEC.	
1	4	CTC4	4C	BA	21/03/22	18/09/25	0,94	0,94	1-MO.	74,0	69,56	36,2	1,5	MEC.	
1	5	CTC4	4C	A	21/03/22	18/09/25	0,64	0,64	1-MO.	74,0	47,36	36,2	1,5	MEC.	
1	6	CTC4	4C	A	21/03/22	18/09/25	8,30	8,30	1-MO.	74,0	614,20	36,2	1,5	MEC.	
1	7	CTC4	4C	BA	11/03/22	18/09/25	17,59	17,59	1-MO.	74,0	1.301,66	36,2	1,5	MEC.	
1	8	CTC4	4C	BA	19/03/22	18/09/25	14,11	14,11	1-MO.	74,0	1.044,14	36,2	1,5	MEC.	
1	9	CTC4	4C	BA	19/03/22	18/09/25	0,34	0,34	1-MO.	74,0	25,16	36,2	1,5	MEC.	
1	10	CTC4	4C	BA	26/03/22	18/09/25	6,64	6,64	1-MO.	74,0	491,36	36,2	1,5	MEC.	
1	11	CTC4	4C	A	25/03/22	18/09/25	1,57	1,57	1-MO.	74,0	116,18	36,2	1,5	MEC.	
1	12	CTC4	4C	B	13/03/22	18/09/25	39,24	39,24	1-MO.	74,0	2.903,76	36,2	1,5	MEC.	
1	13	CTC4	4C	B	12/03/22	18/09/25	0,60	0,60	1-MO.	74,0	44,40	36,2	1,5	MEC.	
1	14	CTC4	4C	A	21/03/22	31/10/25	18,72	18,72	1-MO.	74,0	1.385,28	36,2	1,5	MEC.	
1	15	CTC4	4C	A	24/03/22	31/10/25	2,60	2,60	1-MO.	74,0	192,40	36,2	1,5	MEC.	
1	16	CTC4	4C	A	26/03/22	31/10/25	2,26	2,26	1-MO.	74,0	167,24	36,2	1,5	MEC.	
1	17	CTC4	4C	A	28/03/22	31/10/25	4,42	4,42	1-MO.	74,0	327,08	36,2	1,5	MEC.	
1	18	CTC4	4C	A	28/03/22	31/10/25	8,26	8,26	1-MO.	74,0	611,24	36,2	1,5	MEC.	
1	19	CTC4	4C	A	30/03/22	31/10/25	3,53	3,53	1-MO.	74,0	261,22	36,2	1,5	MEC.	
1	20	CTC4	4C	A	28/03/22	31/10/25	24,85	24,85	1-MO.	74,0	1.838,90	36,2	1,5	MEC.	
1	21	CTC4	4C	A	20/03/22	31/10/25	13,01	13,01	1-MO.	74,0	962,74	36,2	1,5	MEC.	
1	22	CTC4	4C	A	22/03/22	31/10/25	10,88	10,88	1-MO.	74,0	805,12	36,2	1,5	MEC.	
1	23	CTC4	4C	A	25/03/22	31/10/25	12,04	12,04	1-MO.	74,0	890,96	36,2	1,5	MEC.	
1	24	CTC4	4C	A	21/03/22	31/10/25	4,49	4,49	1-MO.	74,0	332,26	36,2	1,5	MEC.	
1	25	CTC4	4C	A	21/03/22	31/10/25	4,44	4,44	1-MO.	74,0	328,56	36,2	1,5	MEC.	
1	26	CTC2994	FORM	A	03/03/26		4,70	0,00	.		0,00	36,2	1,5	N/D	
1	27	CTC2994	FORM	A	06/03/26		1,23	0,00	.		0,00	36,2	1,5	N/D	
1	28	CTC2994	FORM	A	04/03/26		3,09	0,00	.		0,00	36,2	1,5	N/D	
1	29	CTC2994	FORM	A	04/03/26		3,48	0,00	.		0,00	36,2	1,5	N/D	
1	30	CTC2994	FORM	A	06/03/26		9,40	0,00	.		0,00	36,2	1,5	N/D	
1	31	CTC2994	FORM	A	04/03/26		8,58	0,00	.		0,00	36,2	1,5	N/D	
Total/Média (1 / 33 · MARRECAS)							268,61	238,13		74,0	17.621,62				

N: 7728329.923
E: 324766.8697
LAT: −20°32'10.1052" (−20.53614034)
LONG: −46°40'52.1273" (−46.68114647)

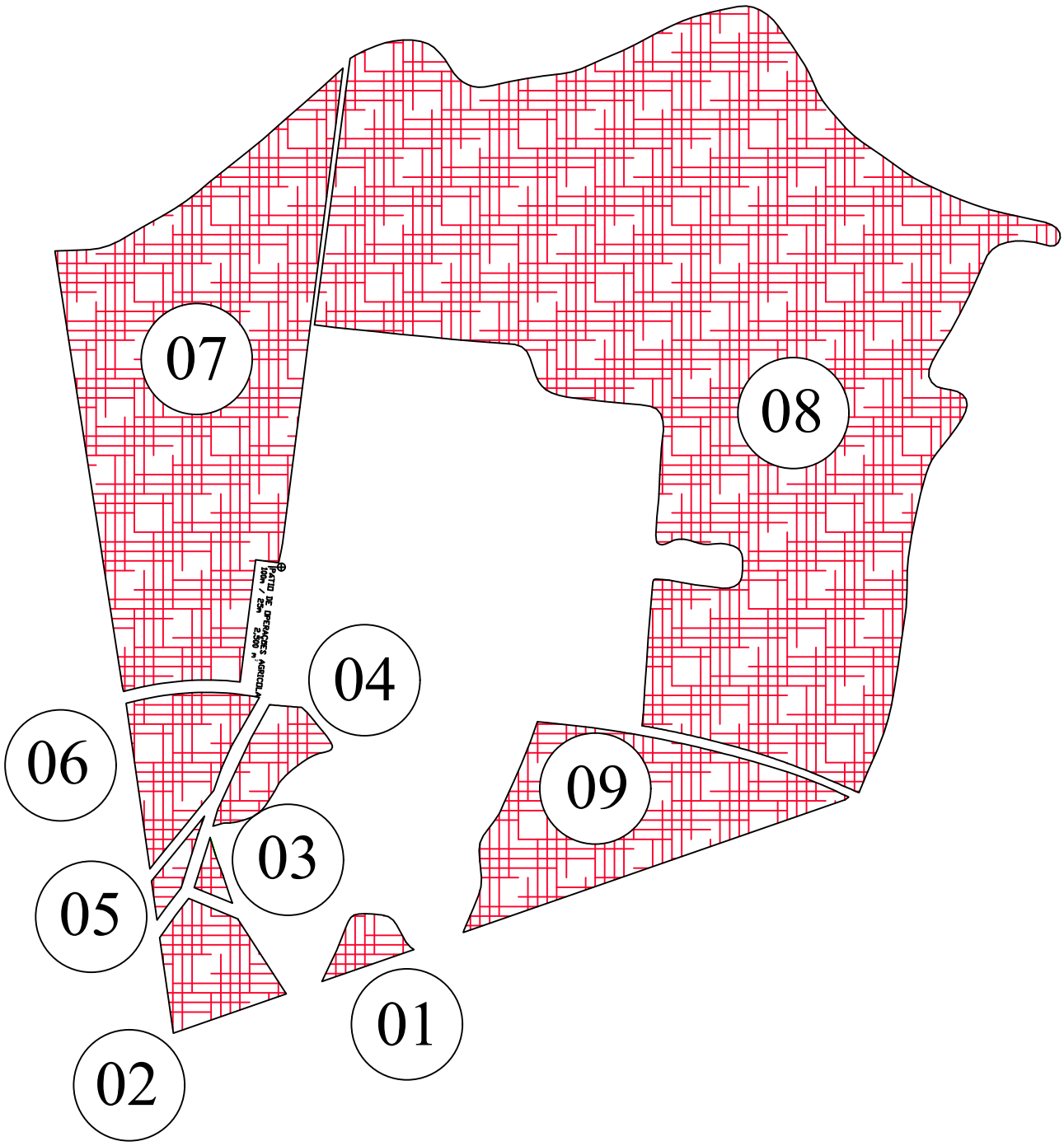

021 -ARADINHO

TABELA DE VARIEDADE	
VARIEDADE	ÁREA
IACSP01-5503	30,33
Total Geral	**30,33**

IAC SP 01-5503

PROJETO: CADERNO DE MAPA 26'27	DATA: 22/01/2026	ESCALA: 1:5000	TOPÓGRAFO: CRISTIAN
FAZENDA: 035 - RIO GRANDE	MUNICÍPIO: PASSOS - MG		ÁREA (ha): 30,33
PROPRIETÁRIO: CIA AGROPASTORIL DO RIO GRANDE	UNIDADE: IPIRANGA PASSOS - MG		CÓDIGO: 035

IPIRANGA AGROINDUSTRIAL

Caderno de Mapas

Bloco	Talhao	Variedade	Estágio de Corte	Amb. Prod.	Data Plantio	Último Corte	Área (ha)	Estimativas Área (ha)	Finalid	Produt.	Prod. Total	Dist.	Esp.	Tipo Corte	Experimento
1 · REG 1			**35 · RIO GRANDE**				**IPIRANGA AGROINDUSTRIAL S.A**								
1	1	IACSP01-5503	3C	A	10/02/23	12/09/25	0,20	0,20	2-MU.	60,0	12,00	24,1	1,5	MEC.	
1	2	IACSP01-5503	3C	A	10/02/23	12/09/25	0,67	0,67	2-MU.	60,0	40,20	24,1	1,5	MEC.	
1	3	IACSP01-5503	3C	A	10/02/23	12/09/25	0,07	0,07	2-MU.	60,0	4,20	24,1	1,5	MEC.	
1	4	IACSP01-5503	3C	A	10/02/23	12/09/25	0,42	0,42	2-MU.	60,0	25,20	24,1	1,5	MEC.	
1	5	IACSP01-5503	3C	A	10/02/23	12/09/25	0,10	0,10	2-MU.	60,0	6,00	24,1	1,5	MEC.	
1	6	IACSP01-5503	3C	A	09/02/23	12/09/25	0,83	0,83	2-MU.	60,0	49,80	24,1	1,5	MEC.	
1	7	IACSP01-5503	3C	C	13/02/23	12/09/25	6,79	6,79	2-MU.	60,0	407,40	24,1	1,5	MEC.	
1	8	IACSP01-5503	3C	A	19/02/23	12/09/25	18,66	18,66	2-MU.	60,0	1.119,60	24,1	1,5	MEC.	
1	9	IACSP01-5503	3C	A	15/02/23	12/09/25	2,59	2,59	2-MU.	60,0	155,40	24,1	1,5	MEC.	
Total/Média (1 / 35 · RIO GRANDE)							30,33	30,33		60,0	1.819,80				

N: 7728619.717
E: 325385.1536
LAT: −20°32'0.8889" (−20.53358025)
LONG: −46°40'30.6823" (−46.67518954)

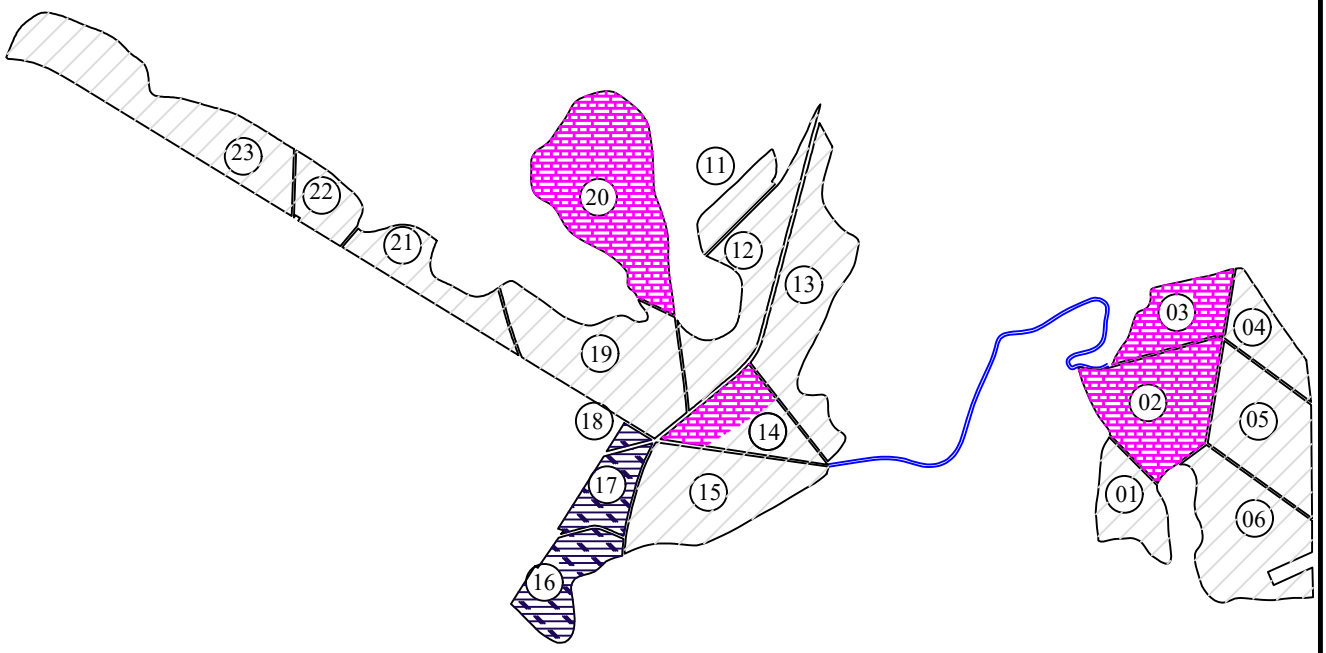

CV-7870
RB 86-7515
RB 97-5375

TABELA DE VARIEDADE	
VARIEDADE	ÁREA
CV7870	5,09
RB867515	57,87
RB975375	18,85
Total Geral	**81,81**

IPIRANGA AGROINDUSTRIAL

PROJETO: CADERNO DE MAPA 26'27	DATA: 22/01/2026	ESCALA: 1:5000	TOPÓGRAFO: CRISTIAN
FAZENDA: 037 - SANTO ANTÔNIO DA BOA VISTA	MUNICÍPIO: PASSOS - MG		ÁREA (ha): 81,81
PROPRIETÁRIO: CIA.AGRO PASTORIO DO RIO GRANDE	UNIDADE: IPIRANGA - PASSOS		CÓDIGO: 037

Caderno de Mapas

Bloco	Talhao	Variedade	Estágio de Corte	Amb. Prod.	Data Plantio	Data Último Corte	Área (ha)	Estimativas Área (ha)	Estimativas Finalid	Estimativas Produt.	Prod. Total	Dist.	Esp.	Tipo Corte	Experimento
1 · REG 1			**37 · STO.A.BOA VISTA**				**IPIRANGA AGROINDUSTRIAL S.A**								
1	1	RB867515	3C	BA	28/04/23	04/08/25	2,72	2,72	1-MO.	82,0	223,04	34,2	1,5	MEC.	
1	2	RB975375	3C	BA	27/04/23	04/08/25	5,77	5,77	1-MO.	82,0	473,14	34,2	1,5	MEC.	
1	3	RB975375	3C	BA	25/04/23	18/03/25	2,89	2,89	1-MO.	82,0	236,98	34,2	1,5	MEC.	
1	4	RB867515	3C	BA	25/04/23	04/08/25	2,34	2,34	1-MO.	80,0	187,20	34,2	1,5	MEC.	
1	5	RB867515	3C	BA	25/04/23	04/08/25	5,17	5,17	1-MO.	80,0	413,60	34,2	1,5	MEC.	
1	6	RB867515	3C	BA	27/04/23	04/08/25	6,23	6,23	1-MO.	80,0	498,40	34,2	1,5	MEC.	
1	11	RB867515	3C	BA	18/04/23	27/06/25	1,46	1,46	1-MO.	80,0	116,80	34,2	1,5	MEC.	
1	12	RB867515	3C	BA	17/04/23	27/06/25	4,98	4,98	1-MO.	80,0	398,40	34,2	1,5	MEC.	
1	13	RB867515	3C	BA	17/04/23	27/06/25	6,61	6,61	1-MO.	80,0	528,80	34,2	1,5	MEC.	
1	14	RB867515	3C	CB	17/04/23	27/06/25	1,83	1,83	1-MO.	80,0	146,40	34,2	1,5	MEC.	
1	14	RB975375	3C	CB	17/04/23	27/06/25	1,66	1,66	1-MO.	80,0	132,80	34,2	1,5	MEC.	
1	15	RB867515	3C	CB	17/04/23	27/06/25	6,37	6,37	1-MO.	80,0	509,60	34,2	1,5	MEC.	
1	16	CV7870	3C	CB	18/04/23	27/06/25	2,84	2,84	1-MO.	80,0	227,20	34,2	1,5	MEC.	
1	17	CV7870	3C	CB	15/04/23	27/06/25	2,00	2,00	1-MO.	80,0	160,00	34,2	1,5	MEC.	
1	18	CV7870	3C	BA	15/04/23	27/06/25	0,25	0,25	1-MO.	80,0	20,00	34,2	1,5	MEC.	
1	19	RB867515	3C	A	16/04/23	27/06/25	7,23	7,23	1-MO.	80,0	578,40	34,2	1,5	MEC.	
1	20	RB975375	3C	BA	18/04/23	27/06/25	8,53	8,53	1-MO.	80,0	682,40	34,2	1,5	MEC.	
1	21	RB867515	3C	BA	21/04/23	27/06/25	3,18	3,18	1-MO.	80,0	254,40	34,2	1,5	MEC.	
1	22	RB867515	3C	BA	17/04/23	27/06/25	1,88	1,88	1-MO.	80,0	150,40	34,2	1,5	MEC.	
1	23	RB867515	3C	A	13/04/23	27/06/25	7,87	7,87	1-MO.	80,0	629,60	34,2	1,5	MEC.	
Total/Média (1 / 37 · STO.A.BOA VISTA)							81,81	81,81		80,3	6.567,56				

N: 7728460.142
E: 319170.7391
LAT: −20°32'3.9678" (−20.53443550)
LONG: −46°44'5.2471" (−46.73479085)

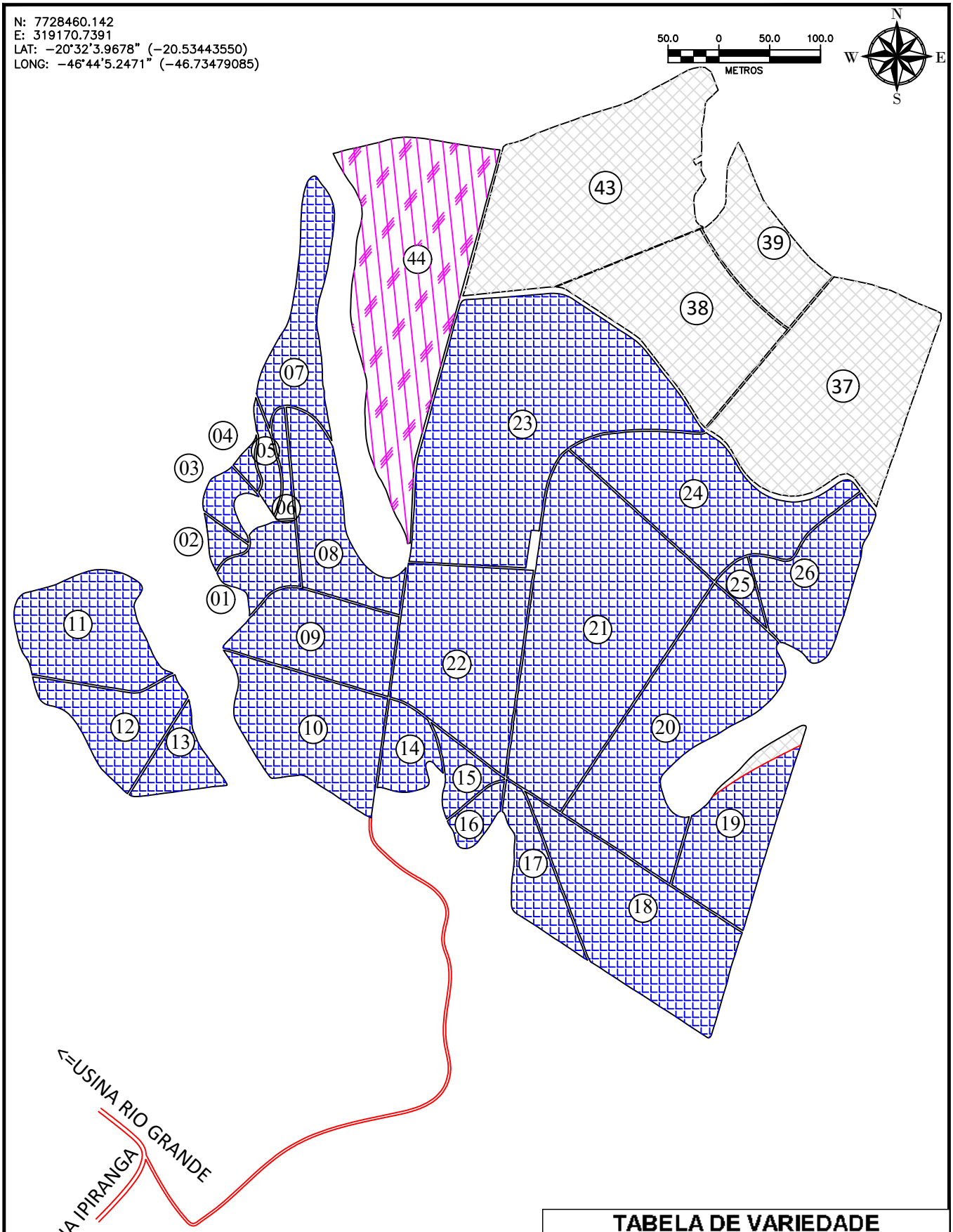

CTC - 2
CTC - 4
CTC -2994

TABELA DE VARIEDADE

VARIEDADE	ÁREA
CTC2	183,05
CTC2994	21,23
CTC4	60,47
Total Geral	**264,75**

IPIRANGA AGROINDUSTRIAL

PROJETO: CADERNO DE MAPA 26'27	DATA: 22/01/2026	ESCALA: 1:5000	TOPÓGRAFO: CRISTIAN
FAZENDA: 038 - SANTO ANTÔNIO DA BOCAINA	MUNICÍPIO: PASSOS MG		ÁREA (ha): 264,75
PROPRIETÁRIO: CIA AÇUCAREIRA RIO GRANDA	UNIDADE: IPIRANGA PASSOS		CÓDIGO: 038

Caderno de Mapas

Bloco	Talhao	Variedade	Estágio de Corte	Amb. Prod.	Data Plantio	Último Corte	Área (ha)	Estimativas Área (ha)	Finalid	Produt.	Prod. Total	Dist.	Esp.	Tipo Corte	Experimento
1 · REG 1			**38 · ST.ANT..BOCAINA**				**IPIRANGA AGROINDUSTRIAL S.A**								
1	1	CTC2	3C	B	24/10/22	13/06/25	2,69	2,69	1-MO.	80,0	215,20	20,4	1,5	MEC.	
1	2	CTC2	3C	A	25/10/22	22/01/25	0,70	0,70	1-MO.	100,0	70,00	20,4	1,5	MEC.	
1	3	CTC2	3C	A	26/10/22	22/01/25	1,17	1,17	1-MO.	100,0	117,00	20,4	1,5	MEC.	
1	4	CTC2	3C	A	21/10/22	22/01/25	0,39	0,39	1-MO.	100,0	39,00	20,4	1,5	MEC.	
1	5	CTC2	3C	A	21/10/22	22/01/25	1,01	1,01	1-MO.	100,0	101,00	20,4	1,5	MEC.	
1	6	CTC2	3C	A	20/10/22	13/06/25	0,79	0,79	1-MO.	85,0	67,15	20,4	1,5	MEC.	
1	7	CTC2	3C	A	21/10/22	29/04/26	5,66	5,24	1-MO.	85,0	445,40	20,4	1,5	MEC.	
1	7	CTC2	3C	A	21/10/22	29/04/26	5,66	0,42	2-MU.	60,0	25,20	20,4	1,5	MEC.	
1	8	CTC2	3C	B	21/10/22	13/06/25	6,43	6,43	1-MO.	85,0	546,55	20,4	1,5	MEC.	
1	9	CTC2	3C	B	21/10/22	13/06/25	7,26	7,26	1-MO.	85,0	617,10	20,4	1,5	MEC.	
1	10	CTC2	3C	B	21/10/22	13/06/25	9,68	9,68	1-MO.	85,0	822,80	20,4	1,5	MEC.	
1	11	CTC2	3C	A	19/10/22	20/01/25	8,21	8,21	1-MO.	95,0	779,95	20,4	1,5	MEC.	
1	12	CTC2	3C	A	19/10/22	20/01/25	5,37	5,37	1-MO.	95,0	510,15	20,4	1,5	MEC.	
1	13	CTC2	3C	A	18/10/22	20/01/25	2,52	2,52	1-MO.	95,0	239,40	20,4	1,5	MEC.	
1	14	CTC2	3C	B	24/10/22	13/06/25	2,56	2,56	1-MO.	80,0	204,80	20,4	1,5	MEC.	
1	15	CTC2	3C	B	24/10/22	13/06/25	1,66	1,66	1-MO.	80,0	132,80	20,4	1,5	MEC.	
1	16	CTC2	3C	B	24/10/22	13/06/25	1,21	1,21	1-MO.	85,0	102,85	20,4	1,5	MEC.	
1	17	CTC2	3C	B	24/10/22	13/06/25	3,52	3,52	1-MO.	85,0	299,20	20,4	1,5	MEC.	
1	18	CTC2	3C	B	24/10/22	13/06/25	13,40	13,40	1-MO.	85,0	1.139,00	20,4	1,5	MEC.	
1	19	CTC2	3C	A	20/10/22	13/06/25	7,07	7,07	1-MO.	85,0	600,95	20,4	1,5	MEC.	
1	19	CTC4	3C	A	20/10/22	13/06/25	0,75	0,75	1-MO.	85,0	63,75	20,4	1,5	MEC.	
1	20	CTC2	3C	A	21/10/22	13/06/25	16,06	16,06	1-MO.	85,0	1.365,10	20,4	1,5	MEC.	
1	21	CTC2	3C	B	22/10/22	13/06/25	24,17	24,17	1-MO.	85,0	2.054,45	20,4	1,5	MEC.	
1	22	CTC2	3C	B	20/10/22	13/06/25	13,10	13,10	1-MO.	85,0	1.113,50	20,4	1,5	MEC.	
1	23	CTC2	3C	B	19/10/22	13/06/25	28,46	28,46	1-MO.	85,0	2.419,10	20,4	1,5	MEC.	
1	24	CTC2	3C	B	23/10/22	13/06/25	12,33	12,33	1-MO.	85,0	1.048,05	20,4	1,5	MEC.	
1	25	CTC2	3C	A	26/10/22	13/06/25	0,89	0,89	1-MO.	85,0	75,65	20,4	1,5	MEC.	
1	26	CTC2	3C	A	26/10/22	13/06/25	6,74	6,74	1-MO.	85,0	572,90	20,4	1,5	MEC.	
1	37	CTC4	5C	A	06/04/21	28/11/25	19,80	19,80	1-MO.	70,0	1.386,00	20,4	1,5	MEC.	
1	38	CTC4	5C	A	08/04/21	28/11/25	12,40	12,40	1-MO.	70,0	868,00	20,4	1,5	MEC.	
1	39	CTC4	5C	A	07/04/21	28/11/25	6,13	6,13	1-MO.	70,0	429,10	20,4	1,5	MEC.	
1	43	CTC4	5C	A	06/04/21	28/11/25	21,39	21,39	1-MO.	70,0	1.497,30	20,4	1,5	MEC.	
1	44	CTC2994	2C	A	18/10/24	28/11/25	21,23	21,23	1-MO.	90,0	1.910,70	20,4	1,5	MEC.	
Total/Média (1 / 38 · ST.ANT..BOCAINA)							264,75	264,75		82,6	21.879,10				

N: 7731051.403
E: 320120.8873
LAT: −20°30'40.0395" (−20.51112208)
LONG: −46°43'31.5059" (−46.72541831)

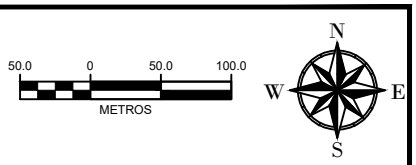

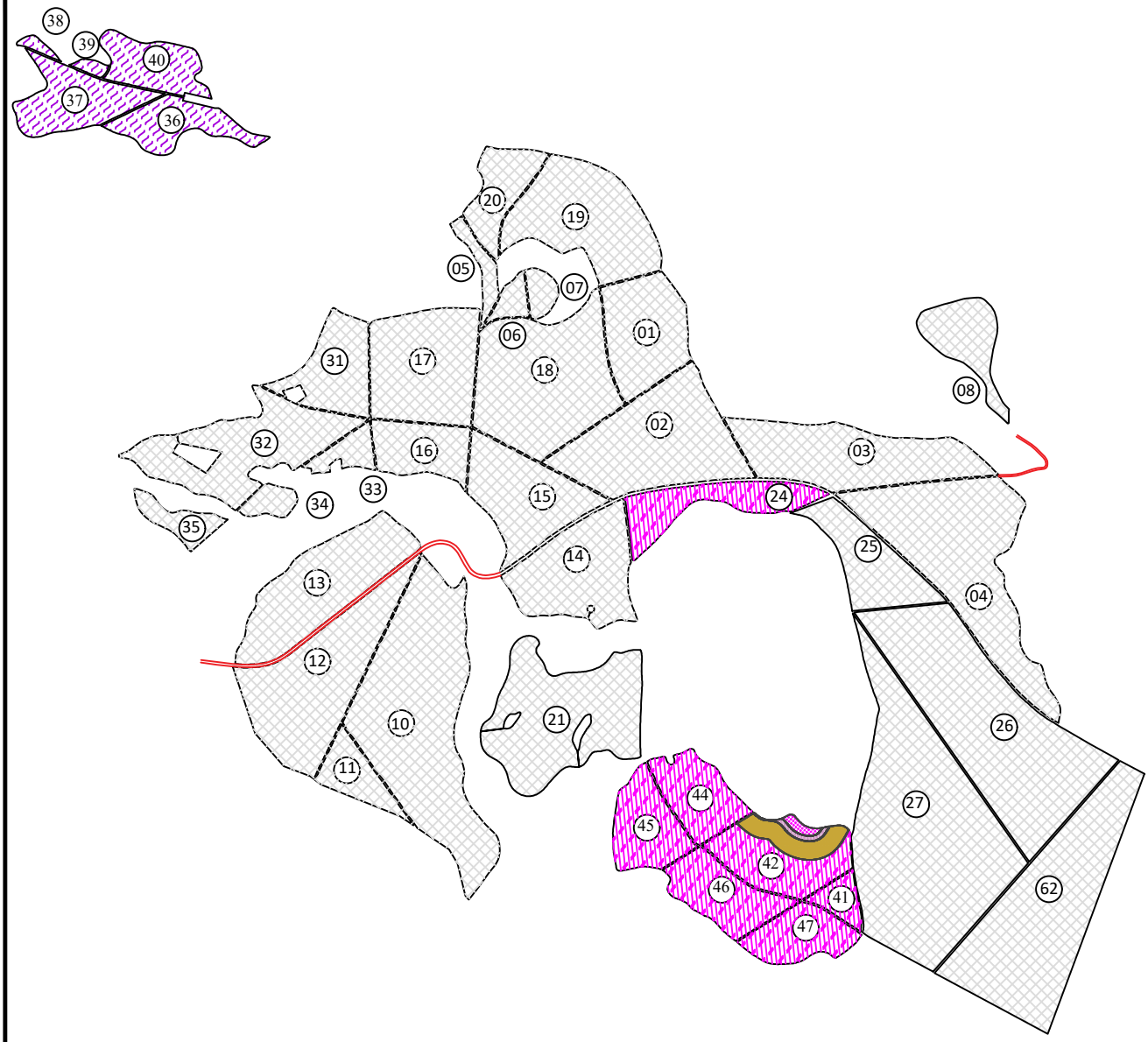

CTC - 4
CTC -2994
CTC -3445
RB 12-7825
RB 07-5322
CTC - 9007

TABELA DE VARIEDADE

VARIEDADE	ÁREA
CTC2994	32,08
CTC3445	0,34
CTC4	292,27
CTC9007	15,17
RB075322	2,03
RB127825	0,32
Total Geral	**342,21**

IPIRANGA AGROINDUSTRIAL

PROJETO: CADERNO DE MAPA 26'27	DATA: 22/01/2026	ESCALA: 1:5000	TOPÓGRAFO: CRISTIAN
FAZENDA: 039 - VARGINHA	MUNICÍPIO: PASSOS - MG		ÁREA (ha): 342,21
PROPRIETÁRIO: CIA AÇUCAREIRA RIO GRANDE	UNIDADE: IPIRANGA PASSOS		CÓDIGO: 039

Caderno de Mapas

Bloco	Talhao	Variedade	Estágio de Corte	Amb. Prod.	Data Plantio	Último Corte	Área (ha)	Estimativas Área (ha)	Finalid	Produt.	Prod. Total	Dist.	Esp.	Tipo Corte	Experimento
1 · REG 1			**39 · VARGINHA**				**IPIRANGA AGROINDUSTRIAL S.A**								
1	1	CTC4	4C	BA	22/03/22	30/09/25	7,84	7,84	1-MO.	70,0	548,80	34,2	1,5	MEC.	
1	2	CTC4	4C	BA	26/03/22	30/09/25	13,93	13,93	1-MO.	70,0	975,10	34,2	1,5	MEC.	
1	3	CTC4	4C	A	24/03/22	30/09/25	11,79	11,79	1-MO.	70,0	825,30	34,2	1,5	MEC.	
1	4	CTC4	4C	A	24/03/22	30/09/25	18,02	18,02	1-MO.	70,0	1.261,40	34,2	1,5	MEC.	
1	5	CTC4	3C	A	13/02/23	30/09/25	1,37	1,37	1-MO.	70,0	95,90	34,2	1,5	MEC.	
1	6	CTC4	3C	A	13/02/23	30/09/25	1,06	1,06	1-MO.	70,0	74,20	34,2	1,5	MEC.	
1	7	CTC4	3C	A	13/02/23	30/09/25	1,15	1,15	1-MO.	70,0	80,50	34,2	1,5	MEC.	
1	8	CTC4	3C	A	13/02/23	01/04/26	4,51	4,51	1-MO.	70,0	315,70	34,2	1,5	MEC.	
1	10	CTC4	4C	A	10/03/22	19/09/25	23,17	23,17	1-MO.	70,0	1.621,90	34,2	1,5	MEC.	
1	11	CTC4	4C	BA	11/03/22	19/09/25	3,07	3,07	1-MO.	70,0	214,90	34,2	1,5	MEC.	
1	12	CTC4	4C	A	11/03/22	19/09/25	13,85	13,85	1-MO.	70,0	969,50	34,2	1,5	MEC.	
1	13	CTC4	4C	A	11/03/22	19/09/25	11,24	11,24	1-MO.	70,0	786,80	34,2	1,5	MEC.	
1	14	CTC4	4C	BA	22/03/22	30/09/25	9,81	9,81	1-MO.	70,0	686,70	34,2	1,5	MEC.	
1	15	CTC4	4C	BA	21/03/22	30/09/25	8,56	8,56	1-MO.	70,0	599,20	34,2	1,5	MEC.	
1	16	CTC4	4C	BA	21/03/22	30/09/25	4,59	4,59	1-MO.	70,0	321,30	34,2	1,5	MEC.	
1	17	CTC4	4C	B	22/03/22	30/09/25	10,86	10,86	1-MO.	70,0	760,20	34,2	1,5	MEC.	
1	18	CTC4	4C	BA	22/03/22	30/09/25	15,70	15,70	1-MO.	70,0	1.099,00	34,2	1,5	MEC.	
1	19	CTC4	4C	C	23/03/22	30/09/25	11,51	11,51	1-MO.	70,0	805,70	34,2	1,5	MEC.	
1	20	CTC4	4C	C	26/03/22	30/09/25	4,13	4,13	1-MO.	70,0	289,10	34,2	1,5	MEC.	
1	21	CTC4	4C	A	28/03/22	30/09/25	14,91	14,91	1-MO.	70,0	1.043,70	34,2	1,5	MEC.	
1	24	CTC2994	FORM	A	05/03/26		5,58	0,00	.		0,00	34,2	1,5	N/D	
1	25	CTC4	5C	A	02/04/21	30/09/25	6,31	6,31	1-MO.	60,0	378,60	34,2	1,5	MEC.	
1	26	CTC4	5C	A	31/03/21	30/09/25	24,00	24,00	1-MO.	60,0	1.440,00	34,2	1,5	MEC.	
1	27	CTC4	5C	A	03/04/21	30/09/25	28,97	28,97	1-MO.	60,0	1.738,20	34,2	1,5	MEC.	
1	31	CTC4	3C	B	08/02/23	30/09/25	5,69	5,69	1-MO.	75,0	426,75	34,2	1,5	MEC.	
1	32	CTC4	3C	A	09/02/23	30/09/25	11,13	11,13	1-MO.	75,0	834,75	34,2	1,5	MEC.	
1	33	CTC4	3C	B	10/02/23	30/09/25	1,65	1,65	1-MO.	75,0	123,75	34,2	1,5	MEC.	
1	34	CTC4	3C	B	11/02/23	30/09/25	1,24	1,24	1-MO.	75,0	93,00	34,2	1,5	MEC.	
1	35	CTC4	3C	A	11/02/23	30/09/25	2,00	2,00	1-MO.	75,0	150,00	34,2	1,5	MEC.	
1	36	CTC9007	1C	NC	27/01/25	06/05/26	4,30	3,94	1-MO.	100,0	394,00	34,2	1,5	MEC.	
1	36	CTC9007	1C	NC	27/01/25	06/05/26	4,30	0,36	2-MU.	70,0	25,20	34,2	1,5	MEC.	
1	37	CTC9007	1C	NC	26/01/25	06/05/26	5,80	0,18	2-MU.	70,0	12,60	34,2	1,5	MEC.	
1	37	CTC9007	1C	NC	26/01/25	06/05/26	5,80	5,62	1-MO.	100,0	562,00	34,2	1,5	MEC.	
1	38	CTC9007	1C	NC	27/01/25	06/05/26	0,37	0,37	1-MO.	100,0	37,00	34,2	1,5	MEC.	
1	39	CTC9007	1C	NC	28/01/25	06/05/26	0,38	0,38	1-MO.	100,0	38,00	34,2	1,5	MEC.	
1	40	CTC9007	1C	NC	28/01/25	06/05/26	4,32	2,06	1-MO.	100,0	206,00	34,2	1,5	MEC.	
1	40	CTC9007	1C	NC	28/01/25	06/05/26	4,32	2,26	2-MU.	70,0	158,20	34,2	1,5	MEC.	
1	41	CTC2994	FORM	A	17/02/26		1,54	0,00	.		0,00	34,2	1,5	N/D	
1	42	CTC2994	FORM	A	19/02/26		5,33	0,00	.		0,00	34,2	1,5	N/D	

Caderno de Mapas

Bloco	Talhao	Variedade	Estágio de Corte	Amb. Prod.	Data Plantio	Último Corte	Área (ha)	Estimativas Área (ha)	Finalid	Produt.	Prod. Total	Dist.	Esp.	Tipo Corte	Experimento
1	42	CTC3445	FORM	A	19/02/26		0,34	0,00	.		0,00	34,2	1,5	N/D	
1	42	RB075322	FORM	A	19/02/26		2,03	0,00	.		0,00	34,2	1,5	N/D	
1	42	RB127825	FORM	A	19/02/26		0,32	0,00	.		0,00	34,2	1,5	N/D	
1	44	CTC2994	FORM	A	19/02/26		4,92	0,00	.		0,00	34,2	1,5	N/D	
1	45	CTC2994	FORM	A	28/02/26		5,19	0,00	.		0,00	34,2	1,5	N/D	
1	46	CTC2994	FORM	A	28/02/26		5,23	0,00	.		0,00	34,2	1,5	N/D	
1	47	CTC2994	FORM	A	18/02/26		4,29	0,00	.		0,00	34,2	1,5	N/D	
1	62	CTC4	5C	A	02/04/21	30/09/25	20,21	20,21	1-MO.	60,0	1.212,60	34,2	1,5	MEC.	
Total/Média (1 / 39 · VARGINHA)							342,21	307,44		69,0	21.205,55				

N: 7728460.142
E: 319170.7391
LAT: −20°32'3.9678" (−20.53443550)
LONG: −46°44'5.2471" (−46.73479085)

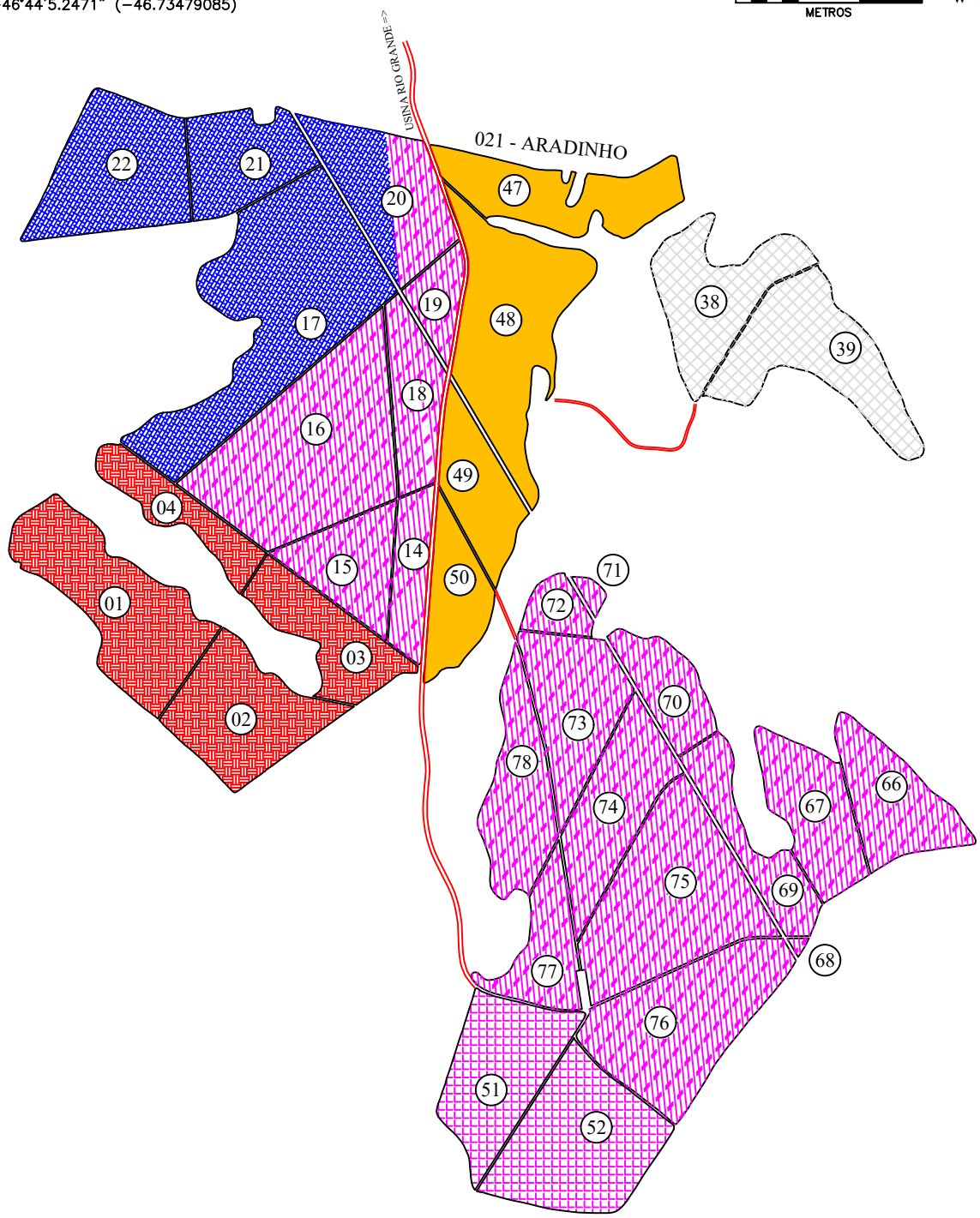

- CTC - 4
- CTC-2994
- SP 80-1816
- CTC - 9007
- RB 96-6928
- RB 98-7935
- CTC - 9002

TABELA DE VARIEDADE

VARIEDADE	ÁREA
CTC2994	125,01
CTC4	14,81
CTC9002	33,96
CTC9007	1,57
RB966928	22,33
RB987935	43,84
SP80-1816	33,65
Total Geral	**275,17**

IPIRANGA AGROINDUSTRIAL

PROJETO: CADERNO DE MAPA 26'27	DATA: 25/05/2026	ESCALA: 1:5000	TOPÓGRAFO: CRISTIAN
FAZENDA: 040 - VIRADOURO	MUNICÍPIO: PASSOS MG		ÁREA (ha): 275,17
PROPRIETÁRIO: CIA AÇUCAREIRA RIO GRANDA	UNIDADE: IPIRANGA PASSOS		CÓDIGO: 040

Caderno de Mapas

Bloco	Talhao	Variedade	Estágio de Corte	Amb. Prod.	Data Plantio	Último Corte	Área (ha)	Estimativas Área (ha)	Finalid	Produt.	Prod. Total	Dist.	Esp.	Tipo Corte	Experimento
1 · REG 1			**40 · VIRADOURO**				**IPIRANGA AGROINDUSTRIAL S.A**								
1	1	CTC9002	4C	C	21/04/22	21/11/25	12,83	12,83	1-MO.	58,0	744,14	27,9	1,5	MEC.	
1	2	CTC9002	4C	B	21/04/22	21/11/25	9,76	9,76	1-MO.	58,0	566,08	27,9	1,5	MEC.	
1	3	CTC9002	4C	A	21/04/22	21/11/25	6,68	6,68	1-MO.	58,0	387,44	27,9	1,5	MEC.	
1	4	CTC9002	4C	A	21/04/22	21/11/25	4,69	4,69	1-MO.	58,0	272,02	27,9	1,5	MEC.	
1	14	CTC2994	4C	A	01/01/22	21/11/25	3,77	3,77	1-MO.	58,0	218,66	27,9	1,5	MEC.	
1	15	CTC2994	4C	A	04/02/22	21/11/25	5,76	5,76	1-MO.	58,0	334,08	27,9	1,5	MEC.	
1	16	CTC2994	4C	A	22/02/22	21/11/25	18,65	18,65	1-MO.	58,0	1.081,70	27,9	1,5	MEC.	
1	17	RB987935	4C	A	19/03/22	21/11/25	21,17	21,17	1-MO.	58,0	1.227,86	27,9	1,5	MEC.	
1	18	CTC2994	4C	A	16/04/22	21/11/25	5,33	5,33	1-MO.	58,0	309,14	27,9	1,5	MEC.	
1	19	CTC2994	4C	A	18/04/22	21/11/25	2,65	2,65	1-MO.	58,0	153,70	27,9	1,5	MEC.	
1	20	CTC2994	4C	BA	16/04/22	21/11/25	4,57	4,57	1-MO.	58,0	265,06	27,9	1,5	MEC.	
1	20	RB987935	4C	BA	16/04/22	21/11/25	4,51	4,51	1-MO.	58,0	261,58	27,9	1,5	MEC.	
1	21	RB987935	4C	BA	16/04/22	21/11/25	6,83	6,83	1-MO.	58,0	396,14	27,9	1,5	MEC.	
1	22	RB987935	4C	BA	16/04/22	21/11/25	11,33	11,33	1-MO.	58,0	657,14	27,9	1,5	MEC.	
1	38	CTC4	3C	A	24/04/23	21/11/25	7,46	7,46	1-MO.	74,0	552,04	27,9	1,5	MEC.	
1	39	CTC4	3C	A	24/04/23	21/11/25	7,35	7,35	1-MO.	74,0	543,90	27,9	1,5	MEC.	
1	39	CTC9007	3C	A	24/04/23	21/11/25	1,57	1,57	1-MO.	74,0	116,18	27,9	1,5	MEC.	
1	47	SP80-1816	4C	C	19/03/22	13/11/25	8,42	8,42	1-MO.	62,0	522,04	27,9	1,5	MEC.	
1	48	SP80-1816	4C	A	17/03/22	21/11/25	14,19	14,19	1-MO.	62,0	879,78	27,9	1,5	MEC.	
1	49	SP80-1816	4C	A	19/03/22	21/11/25	5,90	5,90	1-MO.	62,0	365,80	27,9	1,5	MEC.	
1	50	SP80-1816	4C	A	17/03/22	21/11/25	5,14	5,14	1-MO.	62,0	318,68	27,9	1,5	MEC.	
1	51	RB966928	4C	A	17/03/22	13/11/25	9,63	9,63	1-MO.	62,0	597,06	27,9	1,5	MEC.	
1	52	RB966928	4C	A	17/03/22	13/11/25	12,70	12,70	1-MO.	62,0	787,40	27,9	1,5	MEC.	
1	66	CTC2994	3C	BA	07/03/23	13/11/25	7,07	7,07	1-MO.	76,0	537,32	27,9	1,5	MEC.	
1	67	CTC2994	3C	BA	13/03/23	13/11/25	7,16	7,16	1-MO.	76,0	544,16	27,9	1,5	MEC.	
1	68	CTC2994	3C	BA	18/03/23	13/11/25	0,13	0,13	1-MO.	76,0	9,88	27,9	1,5	MEC.	
1	69	CTC2994	3C	BA	16/03/23	13/11/25	5,20	5,20	1-MO.	76,0	395,20	27,9	1,5	MEC.	
1	70	CTC2994	3C	B	18/03/23	13/11/25	4,46	4,46	1-MO.	76,0	338,96	27,9	1,5	MEC.	
1	71	CTC2994	3C	B	18/03/23	13/11/25	0,45	0,45	1-MO.	76,0	34,20	27,9	1,5	MEC.	
1	72	CTC2994	3C	B	18/03/23	13/11/25	2,03	2,03	1-MO.	76,0	154,28	27,9	1,5	MEC.	
1	73	CTC2994	3C	B	15/03/23	13/11/25	8,13	8,13	1-MO.	76,0	617,88	27,9	1,5	MEC.	
1	74	CTC2994	3C	CB	15/03/23	13/11/25	8,27	8,27	1-MO.	76,0	628,52	27,9	1,5	MEC.	
1	75	CTC2994	3C	BA	14/03/23	13/11/25	15,42	15,42	1-MO.	76,0	1.171,92	27,9	1,5	MEC.	
1	76	CTC2994	3C	BA	11/03/23	13/11/25	13,31	13,31	1-MO.	76,0	1.011,56	27,9	1,5	MEC.	
1	77	CTC2994	3C	A	15/03/23	13/11/25	5,06	5,06	1-MO.	76,0	384,56	27,9	1,5	MEC.	
1	78	CTC2994	3C	CB	16/03/23	13/11/25	7,59	7,59	1-MO.	76,0	576,84	27,9	1,5	MEC.	
Total/Média (1 / 40 · VIRADOURO)							275,17	275,17		65,3	17.962,90				

N: 7707971.426
E: 370347.7445
LAT: −20°43'25.4819" (−20.72374498)
LONG: −46°14'43.9429" (−46.24553970)

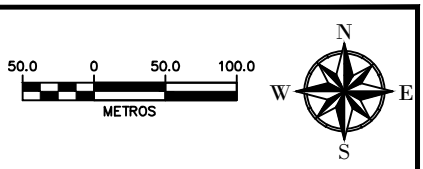

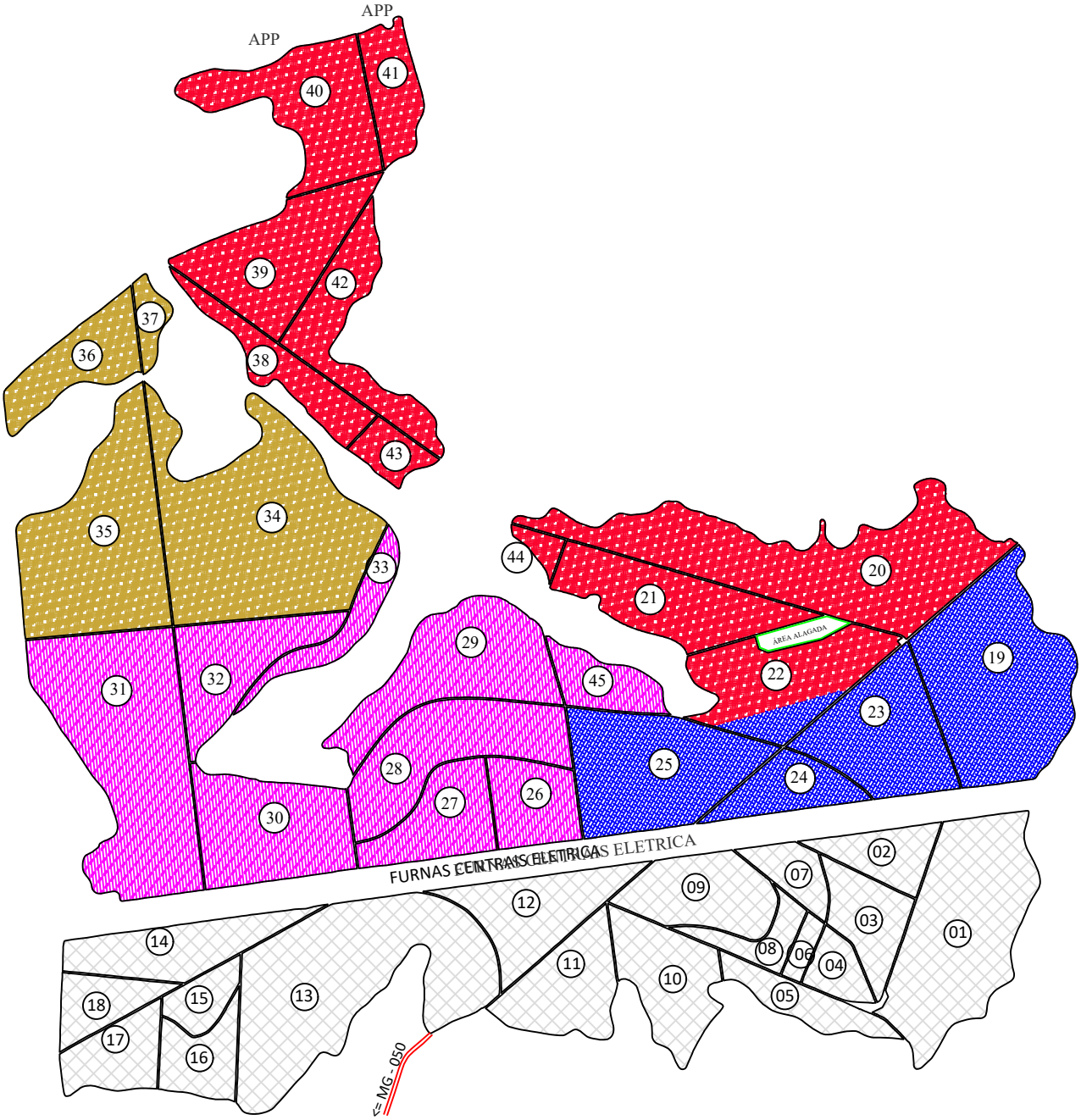

CTC - 4
CTC - 2994
RB 98-7935
IAC SP 01-5503
IAC SP 95-5094

TABELA DE VARIEDADE	
VARIEDADE	ÁREA
CTC2994	101,94
CTC4	137,27
IACSP01-5503	100,55
IACSP95-5094	61,81
RB987935	60,89
Total Geral	**462,46**

IPIRANGA AGROINDUSTRIAL	PROJETO: CADERNO DE MAPA 26'27	DATA: 22/01/2026	ESCALA: 1:5000	TOPÓGRAFO: CRISTIAN
	FAZENDA: 041 - BELA VISTA	MUNICÍPIO: SAO JOSÉ DA BARRA	ÁREA (ha): 462,46
	PROPRIETÁRIO: AGRO PECUÁRIA VALE DO RIO GRANDE	UNIDADE: IPIRANGA PASSOS - MG	ÁREA (ha): 041

Caderno de Mapas

Bloco	Talhao	Variedade	Estágio de Corte	Amb. Prod.	Data Plantio	Último Corte	Área (ha)	Estimativas Área (ha)	Finalid	Produt.	Prod. Total	Dist.	Esp.	Tipo Corte	Experimento
1 · REG 1			**41 · BELA VISTA**				**IPIRANGA AGROINDUSTRIAL S.A**								
1	1	CTC4	4C	B	10/04/22	14/08/25	21,13	21,13	1-MO.	74,0	1.563,62	33,4	1,5	MEC.	
1	2	CTC4	4C	B	12/04/22	13/08/25	4,67	4,67	1-MO.	74,0	345,58	33,4	1,5	MEC.	
1	3	CTC4	4C	A	13/04/22	13/08/25	5,88	5,88	1-MO.	74,0	435,12	33,4	1,5	MEC.	
1	4	CTC4	4C	A	12/04/22	13/08/25	2,82	2,82	1-MO.	74,0	208,68	33,4	1,5	MEC.	
1	5	CTC4	4C	B	11/04/22	14/08/25	4,69	4,69	1-MO.	74,0	347,06	33,4	1,5	MEC.	
1	6	CTC4	4C	A	11/04/22	13/08/25	1,17	1,17	1-MO.	74,0	86,58	33,4	1,5	MEC.	
1	7	CTC4	4C	C	13/04/22	13/08/25	3,24	3,24	1-MO.	74,0	239,76	33,4	1,5	MEC.	
1	8	CTC4	4C	C	14/04/22	13/08/25	2,98	2,98	1-MO.	74,0	220,52	33,4	1,5	MEC.	
1	9	CTC4	4C	C	15/04/22	13/08/25	8,83	8,83	1-MO.	74,0	653,42	33,4	1,5	MEC.	
1	10	CTC4	4C	B	16/04/22	14/08/25	9,15	9,15	1-MO.	74,0	677,10	33,4	1,5	MEC.	
1	11	CTC4	4C	B	15/04/22	14/08/25	8,74	8,74	1-MO.	74,0	646,76	33,4	1,5	MEC.	
1	12	CTC4	4C	C	16/04/22	13/08/25	9,45	9,45	1-MO.	74,0	699,30	33,4	1,5	MEC.	
1	13	CTC4	4C	B	14/04/22	14/08/25	28,04	28,04	1-MO.	74,0	2.074,96	33,4	1,5	MEC.	
1	14	CTC4	4C	C	15/04/22	13/08/25	8,62	8,62	1-MO.	74,0	637,88	33,4	1,5	MEC.	
1	15	CTC4	4C	C	16/04/22	14/08/25	3,05	3,05	1-MO.	74,0	225,70	33,4	1,5	MEC.	
1	16	CTC4	4C	B	15/04/22	14/08/25	4,98	4,98	1-MO.	74,0	368,52	33,4	1,5	MEC.	
1	17	CTC4	4C	C	16/04/22	14/08/25	5,56	5,56	1-MO.	74,0	411,44	33,4	1,5	MEC.	
1	18	CTC4	4C	C	15/04/22	13/08/25	4,27	4,27	1-MO.	74,0	315,98	33,4	1,5	MEC.	
1	19	RB987935	3C	B	15/04/23	25/07/25	22,43	22,43	1-MO.	74,0	1.659,82	33,4	1,5	MEC.	
1	20	IACSP01-5503	3C	B	19/04/23	25/07/25	27,37	27,37	1-MO.	80,0	2.189,60	33,4	1,5	MEC.	
1	21	IACSP01-5503	3C	B	06/05/23	25/07/25	12,08	12,08	1-MO.	80,0	966,40	33,4	1,5	MEC.	
1	22	IACSP01-5503	3C	B	06/05/23	25/07/25	9,10	9,10	1-MO.	80,0	728,00	33,4	1,5	MEC.	
1	22	RB987935	3C	B	06/05/23	25/07/25	3,85	3,85	1-MO.	80,0	308,00	33,4	1,5	MEC.	
1	23	RB987935	3C	A	15/02/23	25/07/25	12,66	12,66	1-MO.	71,0	898,86	33,4	1,5	MEC.	
1	24	RB987935	3C	A	04/03/23	04/08/25	5,40	5,40	1-MO.	71,0	383,40	33,4	1,5	MEC.	
1	25	RB987935	3C	B	12/03/23	04/08/25	16,55	16,55	1-MO.	71,0	1.175,05	33,4	1,5	MEC.	
1	26	CTC2994	3C	C	12/02/23	04/08/25	6,27	6,27	1-MO.	71,0	445,17	33,4	1,5	MEC.	
1	27	CTC2994	3C	C	16/03/23	04/08/25	7,76	7,76	1-MO.	71,0	550,96	33,4	1,5	MEC.	
1	28	CTC2994	3C	B	12/03/23	04/08/25	13,58	13,58	1-MO.	71,0	964,18	33,4	1,5	MEC.	
1	29	CTC2994	3C	B	25/03/23	04/08/25	14,94	14,94	1-MO.	71,0	1.060,74	33,4	1,5	MEC.	
1	30	CTC2994	3C	C	23/03/23	04/08/25	13,65	13,65	1-MO.	71,0	969,15	33,4	1,5	MEC.	
1	31	CTC2994	3C	C	28/01/23	04/08/25	27,16	27,16	1-MO.	71,0	1.928,36	33,4	1,5	MEC.	
1	32	CTC2994	3C	C	30/01/23	04/08/25	9,59	9,59	1-MO.	71,0	680,89	33,4	1,5	MEC.	
1	33	CTC2994	4C	C	31/03/23	04/08/25	4,36	4,36	1-MO.	71,0	309,56	33,4	1,5	MEC.	
1	34	IACSP95-5094	3C	B	29/01/23	23/07/25	30,56	30,56	1-MO.	65,0	1.986,40	33,4	1,5	MEC.	
1	35	IACSP95-5094	3C	A	28/01/23	23/07/25	21,80	21,80	1-MO.	65,0	1.417,00	33,4	1,5	MEC.	
1	36	IACSP95-5094	3C	C	31/01/23	23/07/25	7,54	7,54	1-MO.	65,0	490,10	33,4	1,5	MEC.	
1	37	IACSP95-5094	3C	C	31/01/23	23/07/25	1,91	1,91	1-MO.	65,0	124,15	33,4	1,5	MEC.	
1	38	IACSP01-5503	3C	B	30/03/23	25/07/25	6,37	6,37	1-MO.	85,0	541,45	33,4	1,5	MEC.	

Caderno de Mapas

Bloco	Talhao	Variedade	Estágio de Corte	Amb. Prod.	Data Plantio	Data Último Corte	Área (ha)	Estimativas Área (ha)	Estimativas Finalid	Estimativas Produt.	Prod. Total	Dist.	Esp.	Tipo Corte	Experimento
1	39	IACSP01-5503	3C	B	31/03/23	25/07/25	13,22	13,22	1-MO.	85,0	1.123,70	33,4	1,5	MEC.	
1	40	IACSP01-5503	3C	C	30/03/23	25/07/25	13,62	13,62	1-MO.	85,0	1.157,70	33,4	1,5	MEC.	
1	41	IACSP01-5503	3C	B	30/03/23	25/07/25	5,49	5,49	1-MO.	85,0	466,65	33,4	1,5	MEC.	
1	42	IACSP01-5503	3C	B	30/03/23	25/07/25	9,43	9,43	1-MO.	85,0	801,55	33,4	1,5	MEC.	
1	43	IACSP01-5503	3C	B	30/03/23	25/07/25	2,75	2,75	1-MO.	85,0	233,75	33,4	1,5	MEC.	
1	44	IACSP01-5503	3C	B	22/04/23	25/07/25	1,12	1,12	1-MO.	85,0	95,20	33,4	1,5	MEC.	
1	45	CTC2994	3C	B	21/04/23	04/08/25	4,63	4,63	1-MO.	65,0	300,95	33,4	1,5	MEC.	
Total/Média (1 / 41 · BELA VISTA)							462,46	462,46		73,8	34.114,72				

N: 7707474.961
E: 371559.8118
LAT: -20°43'41.9297" (-20.72831381)
LONG: -46°14'2.1753" (-46.23393758)

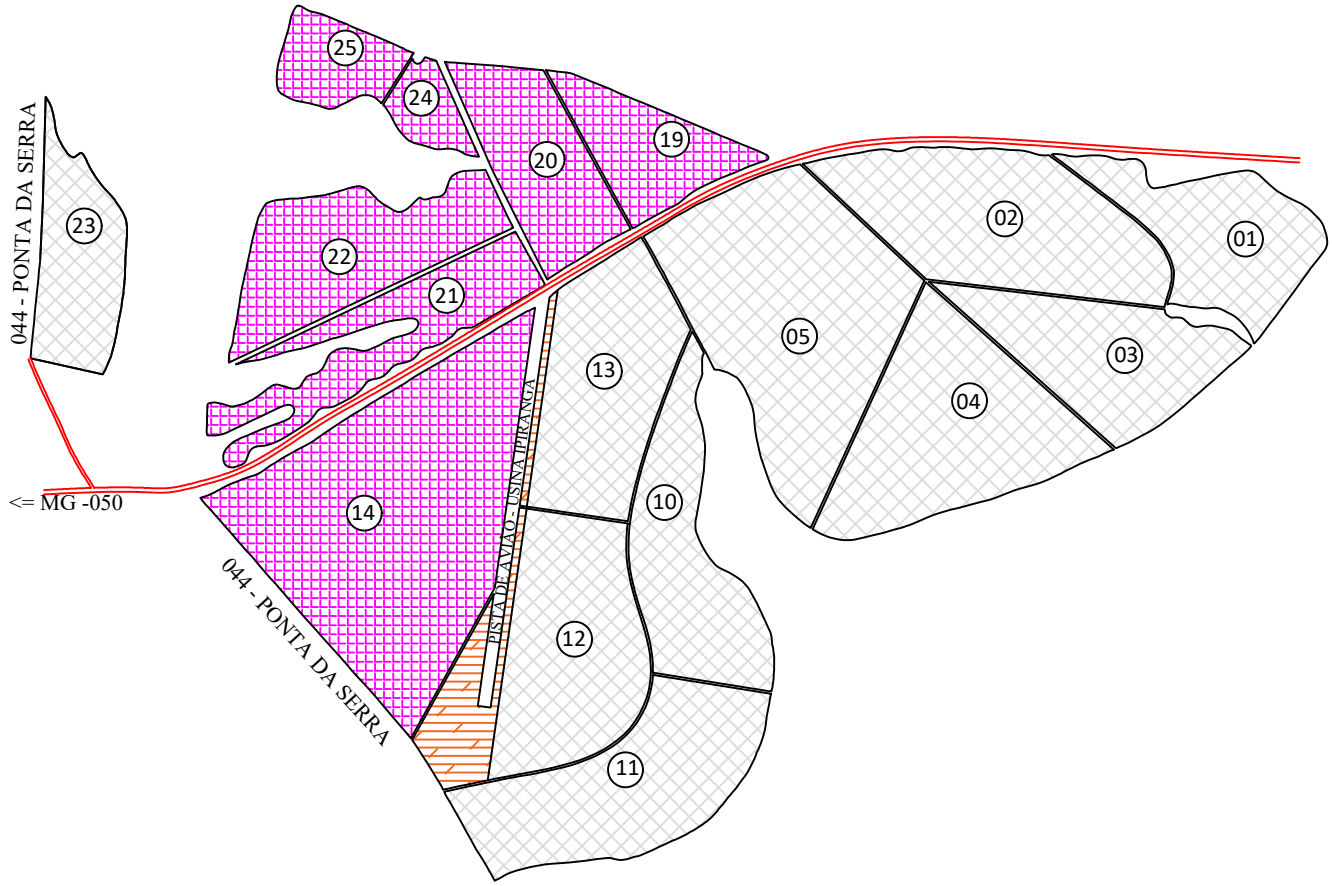

CTC - 4
RB 96-6928
CTC - 9001

TABELA DE VARIEDADE

VARIEDADE	ÁREA
CTC4	165,06
CTC9001	5,84
RB966928	85,94
Total Geral	**256,84**

IPIRANGA AGROINDUSTRIAL

PROJETO: CADERNO DE MAPA 26'27	DATA: 29/01/2026	ESCALA: 1:5000	TOPÓGRAFO: CRISTIAN
FAZENDA: 042 - MONJOLINHO	MUNICÍPIO: SÃO JOSÉ DA BARRA		ÁREA (ha): 256,84
PROPRIETÁRIO: AGROPECUARIA VALE DO RIO GRANDE	UNIDADE: IPIRANGA PASSOS - MG		ÁREA (ha): 042

Caderno de Mapas

Bloco	Talhao	Variedade	Estágio de Corte	Amb. Prod.	Data Plantio	Data Último Corte	Área (ha)	Estimativas Área (ha)	Estimativas Finalid	Estimativas Produt.	Prod. Total	Dist.	Esp.	Tipo Corte	Experimento
1 · REG 1			**42 · MONJOLINHO**				**IPIRANGA AGROINDUSTRIAL S.A**								
1	1	CTC4	4C	C	11/03/22	12/08/25	12,09	12,09	1-MO.	78,0	943,02	41	1,5	MEC.	
1	2	CTC4	4C	C	10/03/22	12/08/25	19,67	19,67	1-MO.	78,0	1.534,26	41	1,5	MEC.	
1	3	CTC4	4C	B	12/03/22	12/08/25	13,17	13,17	1-MO.	78,0	1.027,26	41	1,5	MEC.	
1	4	CTC4	4C	B	12/03/22	12/08/25	19,70	19,70	1-MO.	78,0	1.536,60	41	1,5	MEC.	
1	5	CTC4	4C	C	12/03/22	12/08/25	27,74	27,74	1-MO.	78,0	2.163,72	41	1,5	MEC.	
1	10	CTC4	4C	B	12/03/22	21/07/25	13,34	13,34	1-MO.	78,0	1.040,52	41	1,5	MEC.	
1	11	CTC4	4C	B	12/03/22	21/07/25	17,81	17,81	1-MO.	78,0	1.389,18	41	1,5	MEC.	
1	12	CTC4	4C	B	10/03/22	21/07/25	16,87	16,87	1-MO.	78,0	1.315,86	41	1,5	MEC.	
1	12	CTC9001	4C	B	10/03/22	21/07/25	5,01	5,01	1-MO.	78,0	390,78	41	1,5	MEC.	
1	13	CTC4	4C	B	10/03/22	21/07/25	15,66	15,66	1-MO.	76,0	1.190,16	41	1,5	MEC.	
1	13	CTC9001	4C	B	10/03/22	21/07/25	0,83	0,83	1-MO.	76,0	63,08	41	1,5	MEC.	
1	14	RB966928	4C	C	04/03/22	21/07/25	36,01	36,01	1-MO.	70,0	2.520,70	41	1,5	MEC.	
1	19	RB966928	4C	C	05/03/22	19/08/25	7,70	7,70	1-MO.	76,0	585,20	41	1,5	MEC.	
1	20	RB966928	4C	C	05/03/22	19/08/25	10,29	10,29	1-MO.	76,0	782,04	41	1,5	MEC.	
1	21	RB966928	4C	C	05/03/22	19/08/25	10,63	10,63	1-MO.	76,0	807,88	41	1,5	MEC.	
1	22	RB966928	4C	C	06/03/22	19/08/25	13,77	13,77	1-MO.	76,0	1.046,52	41	1,5	MEC.	
1	23	CTC4	4C	C	10/03/22	02/09/25	9,01	9,01	1-MO.	76,0	684,76	41	1,5	MEC.	
1	24	RB966928	4C	C	06/03/22	19/08/25	2,73	2,73	1-MO.	76,0	207,48	41	1,5	MEC.	
1	25	RB966928	4C	C	06/03/22	19/08/25	4,81	4,81	1-MO.	76,0	365,56	41	1,5	MEC.	
Total/Média (1 / 42 · MONJOLINHO)							256,84	256,84		76,3	19.594,58				

N: 7708305.162
E: 358446.4314
LAT: −20°43'11.5145" (−20.71986513)
LONG: −46°21'35.2363" (−46.35978785)

50.0 0 50.0 100.0
METROS

N W E S

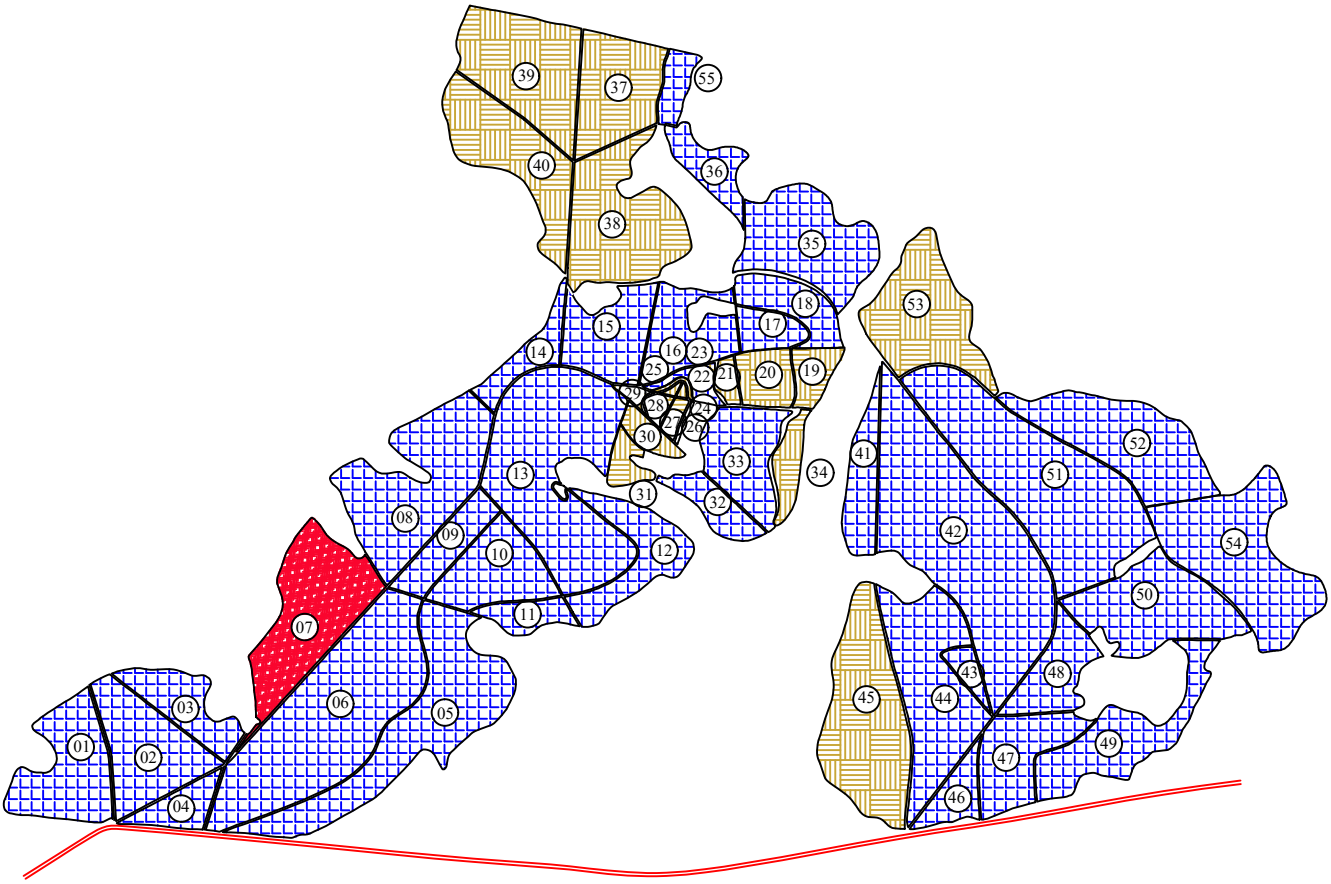

CTC - 2
RB 98-8082
IACSP 01-5503

TABELA DE VARIEDADE	
VARIEDADE	ÁREA
CTC2	293,23
IACSP01-5503	11,73
RB987935	62,39
Total Geral	**367,35**

IPIRANGA AGROINDUSTRIAL

PROJETO: CADERNO DE MAPA 26'27	DATA: 29/01/2026	ESCALA: 1:5000	TOPÓGRAFO: CRISTIAN
FAZENDA: 043 - NOSSA SENHORA DO CARMO	MUNICÍPIO: ALPINOPOLIS - MG		ÁREA (ha): 367,35
PROPRIETÁRIO: ITAIQUARA ALIMENTOS S.A	UNIDADE: IPIRANGA PASSOS - MG		

Caderno de Mapas

Bloco	Talhao	Variedade	Estágio de Corte	Amb. Prod.	Data Plantio	Último Corte	Área (ha)	Estimativas Área (ha)	Finalid	Produt.	Prod. Total	Dist.	Esp.	Tipo Corte	Experimento
1 · REG 1			43 · N.S.CARMO				IPIRANGA AGROINDUSTRIAL S.A								
1	1	CTC2	4C	BA	07/03/22	08/08/25	8,18	8,18	1-MO.	80,0	654,40	29	1,5	MEC.	
1	2	CTC2	4C	BA	07/03/22	08/08/25	8,39	8,39	1-MO.	80,0	671,20	29	1,5	MEC.	
1	3	CTC2	4C	BA	07/03/22	08/08/25	4,57	4,57	1-MO.	80,0	365,60	29	1,5	MEC.	
1	4	CTC2	4C	BA	07/03/22	08/08/25	2,53	2,53	1-MO.	80,0	202,40	29	1,5	MEC.	
1	5	CTC2	4C	A	07/03/22	08/08/25	15,12	15,12	1-MO.	80,0	1.209,60	29	1,5	MEC.	
1	6	CTC2	4C	BA	07/03/22	08/08/25	21,73	21,73	1-MO.	80,0	1.738,40	29	1,5	MEC.	
1	7	IACSP01-5503	5C	BA	02/03/22	08/08/25	11,73	11,73	1-MO.	58,0	680,34	29	1,5	MEC.	
1	8	CTC2	4C	BA	02/03/22	08/08/25	14,05	14,05	1-MO.	80,0	1.124,00	29	1,5	MEC.	
1	9	CTC2	4C	BA	02/03/22	08/08/25	3,67	3,67	1-MO.	80,0	293,60	29	1,5	MEC.	
1	10	CTC2	4C	BA	04/03/22	08/08/25	6,43	6,43	1-MO.	80,0	514,40	29	1,5	MEC.	
1	11	CTC2	4C	A	04/03/22	08/08/25	2,16	2,16	1-MO.	80,0	172,80	29	1,5	MEC.	
1	12	CTC2	4C	DC	04/03/22	08/08/25	6,04	6,04	1-MO.	80,0	483,20	29	1,5	MEC.	
1	13	CTC2	4C	CB	04/03/22	08/08/25	19,71	19,71	1-MO.	80,0	1.576,80	29	1,5	MEC.	
1	14	CTC2	4C	CB	04/03/22	08/08/25	2,87	2,87	1-MO.	80,0	229,60	29	1,5	MEC.	
1	15	CTC2	4C	CB	04/03/22	08/08/25	6,16	6,16	1-MO.	80,0	492,80	29	1,5	MEC.	
1	16	CTC2	4C	CB	03/03/22	08/08/25	5,48	5,48	1-MO.	80,0	438,40	29	1,5	MEC.	
1	17	CTC2	4C	CB	03/03/22	08/08/25	2,18	2,18	1-MO.	80,0	174,40	29	1,5	MEC.	
1	18	CTC2	4C	DC	03/03/22	08/08/25	3,83	3,83	1-MO.	80,0	306,40	29	1,5	MEC.	
1	19	RB987935	5C	DC	01/01/21	08/08/25	2,00	2,00	1-MO.	65,0	130,00	29	1,5	MEC.	
1	20	RB987935	5C	CB	01/01/21	08/08/25	2,81	2,81	1-MO.	65,0	182,65	29	1,5	MEC.	
1	21	RB987935	5C	CB	01/01/21	08/08/25	0,81	0,81	1-MO.	65,0	52,65	29	1,5	MEC.	
1	22	CTC2	4C	CB	04/03/22	08/08/25	1,18	1,18	1-MO.	65,0	76,70	29	1,5	MEC.	
1	23	RB987935	5C	CB	01/01/21	08/08/25	0,18	0,18	1-MO.	65,0	11,70	29	1,5	MEC.	
1	24	RB987935	5C	CB	01/01/21	08/08/25	0,08	0,08	1-MO.	65,0	5,20	29	1,5	MEC.	
1	25	RB987935	5C	CB	01/01/21	08/08/25	0,10	0,10	1-MO.	65,0	6,50	29	1,5	MEC.	
1	26	RB987935	5C	CB	01/01/21	08/08/25	0,14	0,14	1-MO.	65,0	9,10	29	1,5	MEC.	
1	27	RB987935	5C	CB	01/01/21	08/08/25	0,53	0,53	1-MO.	65,0	34,45	29	1,5	MEC.	
1	28	RB987935	5C	CB	01/01/21	08/08/25	0,54	0,54	1-MO.	65,0	35,10	29	1,5	MEC.	
1	29	RB987935	5C	CB	01/01/21	08/08/25	0,40	0,40	1-MO.	65,0	26,00	29	1,5	MEC.	
1	30	RB987935	5C	CB	01/01/21	08/08/25	1,39	1,39	1-MO.	65,0	90,35	29	1,5	MEC.	
1	31	RB987935	5C	DC	01/01/21	08/08/25	1,41	1,41	1-MO.	65,0	91,65	29	1,5	MEC.	
1	32	CTC2	4C	DC	07/03/22	08/08/25	2,75	2,75	1-MO.	80,0	220,00	29	1,5	MEC.	
1	33	CTC2	4C	CB	05/03/22	08/08/25	6,39	6,39	1-MO.	80,0	511,20	29	1,5	MEC.	
1	34	RB987935	5C	DC	01/01/21	08/08/25	2,08	2,08	1-MO.	65,0	135,20	29	1,5	MEC.	
1	35	CTC2	4C	DC	28/10/22	08/08/25	9,97	9,97	1-MO.	80,0	797,60	29	1,5	MEC.	
1	36	CTC2	4C	DC	28/10/22	08/08/25	3,21	3,21	1-MO.	80,0	256,80	29	1,5	MEC.	
1	37	RB987935	4C	CB	04/04/22	08/08/25	7,80	7,80	1-MO.	73,0	569,40	29	1,5	MEC.	
1	38	RB987935	4C	CB	26/03/22	08/08/25	11,60	11,60	1-MO.	73,0	846,80	29	1,5	MEC.	
1	39	RB987935	4C	CB	28/03/22	08/08/25	10,92	10,92	1-MO.	73,0	797,16	29	1,5	MEC.	

Caderno de Mapas

Bloco	Talhao	Variedade	Estágio de Corte	Amb. Prod.	Data Plantio	Data Último Corte	Área (ha)	Estimativas Área (ha)	Estimativas Finalid	Estimativas Produt.	Prod. Total	Dist.	Esp.	Tipo Corte	Experimento
1	40	RB987935	4C	CB	24/03/22	08/08/25	9,40	9,40	1-MO.	73,0	686,20	29	1,5	MEC.	
1	41	CTC2	4C	B	04/03/22	22/08/25	3,96	3,96	1-MO.	73,0	289,08	29	1,5	MEC.	
1	42	CTC2	4C	CB	05/03/22	08/08/25	25,74	25,74	1-MO.	73,0	1.879,02	29	1,5	MEC.	
1	43	CTC2	4C	CB	05/03/22	22/08/25	1,11	1,11	1-MO.	73,0	81,03	29	1,5	MEC.	
1	44	CTC2	4C	CB	07/03/22	08/08/25	12,17	12,17	1-MO.	73,0	888,41	29	1,5	MEC.	
1	45	CTC2	4C	CB	24/03/22	08/08/25	13,53	13,53	1-MO.	73,0	987,69	29	1,5	MEC.	
1	46	CTC2	4C	CB	05/03/22	08/08/25	2,47	2,47	1-MO.	73,0	180,31	29	1,5	MEC.	
1	47	CTC2	4C	CB	05/03/22	08/08/25	6,16	6,16	1-MO.	73,0	449,68	29	1,5	MEC.	
1	48	CTC2	4C	CB	07/03/22	08/08/25	4,68	4,68	1-MO.	73,0	341,64	29	1,5	MEC.	
1	49	CTC2	4C	B	05/03/22	22/08/25	7,97	7,97	1-MO.	73,0	581,81	29	1,5	MEC.	
1	50	CTC2	4C	B	05/03/22	08/08/25	10,13	10,13	1-MO.	73,0	739,49	29	1,5	MEC.	
1	51	CTC2	4C	B	05/03/22	22/08/25	21,54	21,54	1-MO.	73,0	1.572,42	29	1,5	MEC.	
1	52	CTC2	4C	B	07/03/22	08/08/25	11,30	11,30	1-MO.	73,0	824,90	29	1,5	MEC.	
1	53	RB987935	4C	B	23/03/22	08/08/25	10,20	10,20	1-MO.	73,0	744,60	29	1,5	MEC.	
1	54	CTC2	4C	B	28/10/22	08/08/25	14,10	14,10	1-MO.	73,0	1.029,30	29	1,5	MEC.	
1	55	CTC2	4C	DC	28/10/22	08/08/25	1,77	1,77	1-MO.	73,0	129,21	29	1,5	MEC.	
Total/Média (1 / 43 · N.S.CARMO)							367,35	367,35		75,2	27.619,34				

N: 7707971.426
E: 370347.7445
LAT: −20°43'25.4819" (−20.72374498)
LONG: −46°14'43.9429" (−46.24553970)

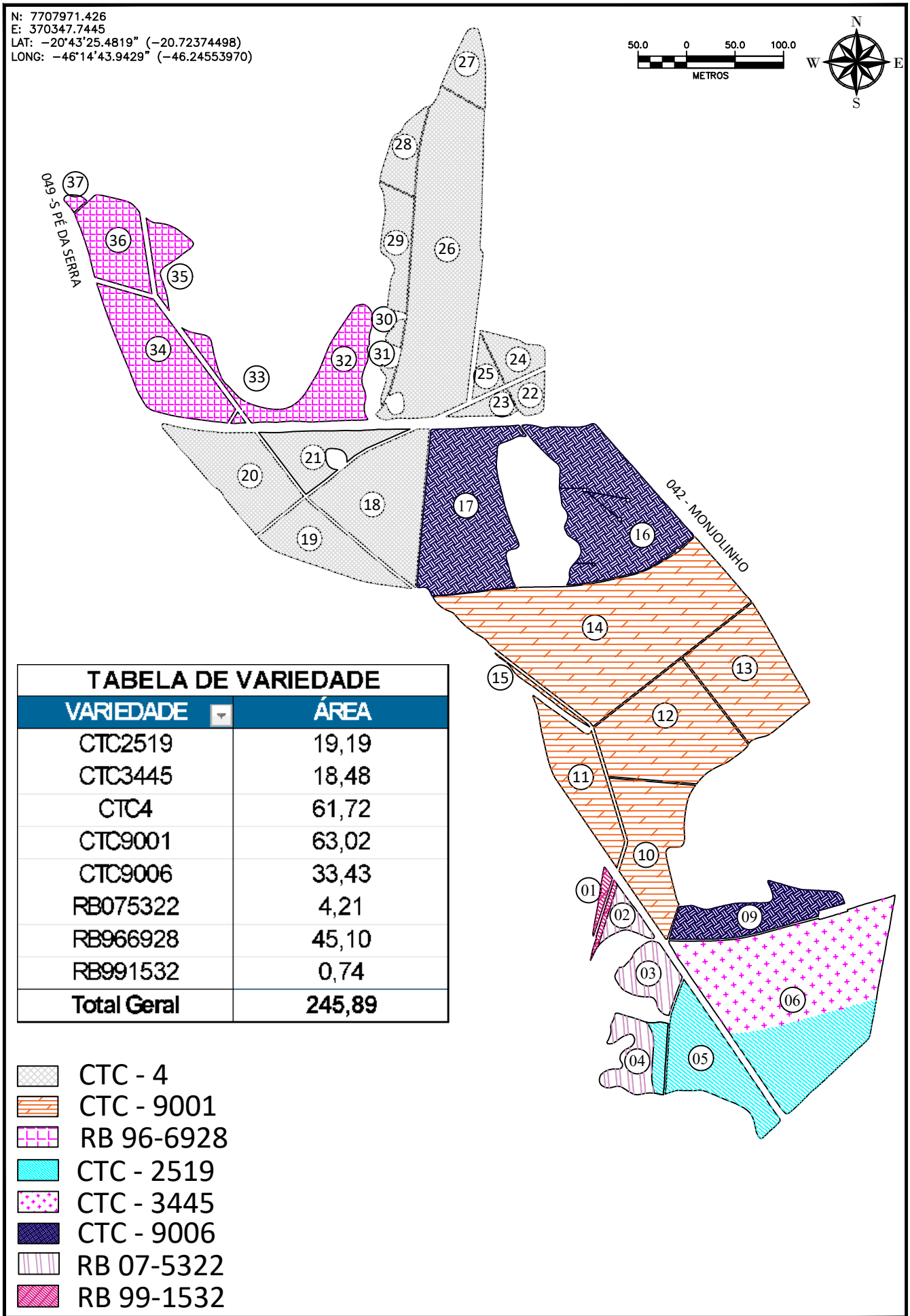

TABELA DE VARIEDADE

VARIEDADE	ÁREA
CTC2519	19,19
CTC3445	18,48
CTC4	61,72
CTC9001	63,02
CTC9006	33,43
RB075322	4,21
RB966928	45,10
RB991532	0,74
Total Geral	**245,89**

- CTC - 4
- CTC - 9001
- RB 96-6928
- CTC - 2519
- CTC - 3445
- CTC - 9006
- RB 07-5322
- RB 99-1532

IPIRANGA AGROINDUSTRIAL

PROJETO	DATA	ESCALA	TOPÓGRAFO
CADERNO DE MAPA 26'27	29/01/2026	1:5000	CRISTIAN
FAZENDA	**MUNICÍPIO**		**ÁREA (ha)**
044 PONTA DA SERRA	SAO JOSÉ DA BARRA		245,89
PROPRIETÁRIO	**UNIDADE**		**ÁREA (ha)**
AGRO PECUÁRIA VALE DO RIO GRANDE	IPIRANGA PASSOS - MG		044

Caderno de Mapas

Bloco	Talhao	Variedade	Estágio de Corte	Amb. Prod.	Data Plantio	Último Corte	Área (ha)	Estimativas Área (ha)	Finalid	Produt.	Prod. Total	Dist.	Esp.	Tipo Corte	Experimento
1 · REG 1			**44 · PONTA SERRA**				**IPIRANGA AGROINDUSTRIAL S.A**								
1	1	RB991532	FORM	A	03/12/25		0,40	0,00	.		0,00	41	1,5	N/D	
1	2	RB075322	FORM	A	03/12/25		1,34	0,00	.		0,00	41	1,5	N/D	
1	2	RB991532	FORM	A	03/12/25		0,34	0,00	.		0,00	41	1,5	N/D	
1	3	RB075322	FORM	A	05/12/25		2,87	0,00	.		0,00	41	1,5	N/D	
1	4	CTC2519	FORM	BA	05/12/25		3,80	0,00	.		0,00	41	1,5	N/D	
1	5	CTC2519	FORM	C	07/12/25		7,21	0,00	.		0,00	41	1,5	N/D	
1	6	CTC2519	FORM	C	15/12/25		8,18	0,00	.		0,00	41	1,5	N/D	
1	6	CTC3445	FORM	C	15/12/25		18,48	0,00	.		0,00	41	1,5	N/D	
1	7	RB966928	4C	A	10/04/22	28/07/25	12,47	12,47	1-MO.	70,0	872,90	41	1,5	MEC.	
1	8	RB966928	4C	A	12/04/22	28/07/25	9,47	9,47	1-MO.	70,0	662,90	41	1,5	MEC.	
1	9	CTC9006	FORM	A	23/12/25		5,26	0,00	.		0,00	41	1,5	N/D	
1	10	CTC9001	4C	A	14/04/22	27/07/25	7,75	7,75	1-MO.	75,0	581,25	41	1,5	MEC.	
1	11	CTC9001	4C	A	14/04/22	27/07/25	6,01	6,01	1-MO.	75,0	450,75	41	1,5	MEC.	
1	12	CTC9001	4C	A	14/04/22	27/07/25	11,93	11,93	1-MO.	75,0	894,75	41	1,5	MEC.	
1	13	CTC9001	4C	A	14/04/22	27/07/25	9,42	9,42	1-MO.	75,0	706,50	41	1,5	MEC.	
1	14	CTC9001	4C	A	14/04/22	27/07/25	27,57	27,57	1-MO.	75,0	2.067,75	41	1,5	MEC.	
1	15	CTC9001	4C	A	14/04/22	27/07/25	0,34	0,34	1-MO.	75,0	25,50	41	1,5	MEC.	
1	16	CTC9006	FORM	C	28/12/25		14,19	0,00	.		0,00	41	1,5	N/D	
1	17	CTC9006	FORM	C	26/12/25		13,98	0,00	.		0,00	41	1,5	N/D	
1	18	CTC4	4C	C	14/04/22	05/09/25	10,38	10,38	1-MO.	75,0	778,50	41	1,5	MEC.	
1	19	CTC4	4C	C	02/04/22	05/09/25	5,30	5,30	1-MO.	75,0	397,50	41	1,5	MEC.	
1	20	CTC4	4C	C	02/04/22	05/09/25	7,27	7,27	1-MO.	75,0	545,25	41	1,5	MEC.	
1	21	CTC4	4C	C	21/04/22	05/09/25	4,09	4,09	1-MO.	75,0	306,75	41	1,5	MEC.	
1	22	CTC4	4C	C	09/03/22	02/09/25	1,09	1,09	1-MO.	75,0	81,75	41	1,5	MEC.	
1	23	CTC4	4C	C	09/03/22	02/09/25	0,97	0,97	1-MO.	76,0	73,72	41	1,5	MEC.	
1	24	CTC4	4C	C	09/03/22	02/09/25	1,90	1,90	1-MO.	76,0	144,40	41	1,5	MEC.	
1	25	CTC4	4C	C	09/03/22	02/09/25	1,01	1,01	1-MO.	76,0	76,76	41	1,5	MEC.	
1	26	CTC4	4C	C	09/03/22	02/09/25	21,82	21,82	1-MO.	76,0	1.658,32	41	1,5	MEC.	
1	27	CTC4	4C	C	09/03/22	02/09/25	2,22	2,22	1-MO.	76,0	168,72	41	1,5	MEC.	
1	28	CTC4	4C	C	09/03/22	02/09/25	2,17	2,17	1-MO.	76,0	164,92	41	1,5	MEC.	
1	29	CTC4	4C	C	09/03/22	02/09/25	2,92	2,92	1-MO.	76,0	221,92	41	1,5	MEC.	
1	30	CTC4	4C	C	09/03/22	02/09/25	0,33	0,33	1-MO.	76,0	25,08	41	1,5	MEC.	
1	31	CTC4	4C	C	09/03/22	02/09/25	0,25	0,25	1-MO.	76,0	19,00	41	1,5	MEC.	
1	32	RB966928	4C	C	03/03/22	15/05/26	6,86	6,86	1-MO.	80,0	548,80	41	1,5	MEC.	
1	33	RB966928	4C	C	02/03/22	05/09/25	0,08	0,08	1-MO.	80,0	6,40	41	1,5	MEC.	
1	34	RB966928	4C	C	03/03/22	05/09/25	9,18	9,18	1-MO.	80,0	734,40	41	1,5	MEC.	
1	35	RB966928	4C	C	03/03/22	05/09/25	1,70	1,70	1-MO.	80,0	136,00	41	1,5	MEC.	
1	36	RB966928	4C	C	03/03/22	05/09/25	5,11	5,11	1-MO.	80,0	408,80	41	1,5	MEC.	
1	37	RB966928	4C	C	03/03/22	05/09/25	0,23	0,23	1-MO.	80,0	18,40	41	1,5	MEC.	

Caderno de Mapas

Bloco	Talhao	Variedade	Estágio de Corte	Amb. Prod.	Data Plantio	Data Último Corte	Área (ha)	Estimativas Área (ha)	Estimativas Finalid	Estimativas Produt.	Prod. Total	Dist. Esp.	Tipo Corte	Experimento
Total/Média (1 / 44 · PONTA SERRA)							245,89	169,84		75,2	12.777,69			

N: 7707971.426
E: 370347.7445
LAT: −20°43'25.4819" (−20.72374498)
LONG: −46°14'43.9429" (−46.24553970)

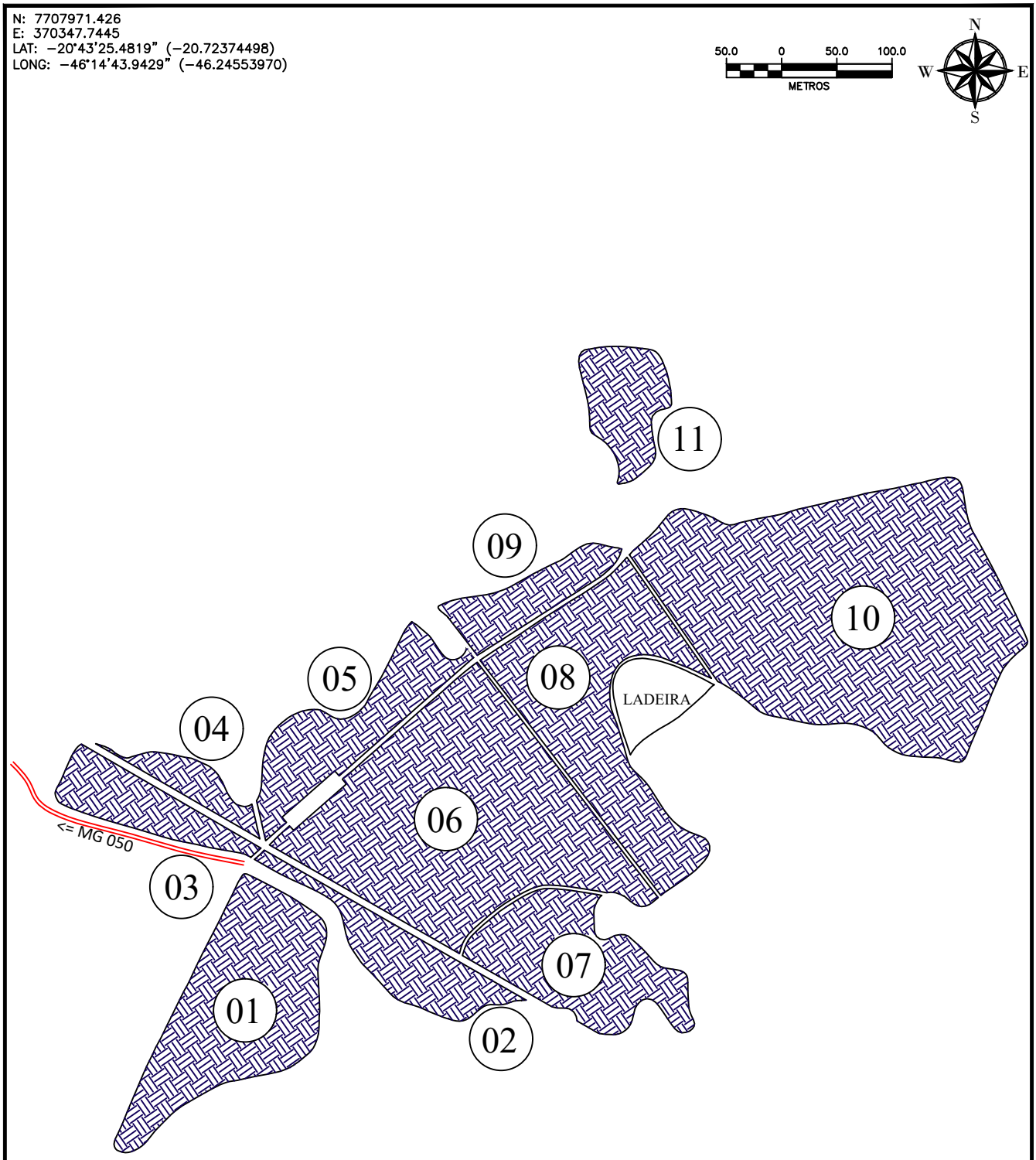

CTC - 9006

TABELA DE VARIEDADE	
VARIEDADE	ÁREA
CTC9006	50,89
Total Geral	**50,89**

IPIRANGA AGROINDUSTRIAL	PROJETO CADERNO DE MAPA 26'27	DATA 29/01/2026	ESCALA 1:5000	TOPÓGRAFO CRISTIAN
	FAZENDA 045 - SÃO SEBSTIÃO DO TAQUARUÇU	MUNICÍPIO SAO JOSÉ DA BARRA		ÁREA (ha) 50,89
	PROPRIETÁRIO AGRO PECUÁRIA VALE DO RIO GRANDE	UNIDADE IPIRANGA PASSOS - MG		ÁREA (ha) 045

Caderno de Mapas

Bloco	Talhao	Variedade	Estágio de Corte	Amb. Prod.	Data Plantio	Último Corte	Área (ha)	Estimativas Área (ha)	Finalid	Produt.	Prod. Total	Dist.	Esp.	Tipo Corte	Experimento
1 · REG 1			**45 · S.SEB.TAQUARUÇU**				**IPIRANGA AGROINDUSTRIAL S.A**								
1	1	CTC9006	3C	A	21/03/23	25/03/26	5,61	5,61	1-MO.	87,0	488,07	16,6	1,5	MEC.	
1	2	CTC9006	3C	A	18/03/23	25/03/26	2,08	2,08	1-MO.	87,0	180,96	16,6	1,5	MEC.	
1	3	CTC9006	3C	A	21/03/23	25/03/26	1,70	1,70	1-MO.	87,0	147,90	16,6	1,5	MEC.	
1	4	CTC9006	3C	A	21/03/23	25/03/26	0,78	0,78	1-MO.	87,0	67,86	16,6	1,5	MEC.	
1	5	CTC9006	3C	A	20/03/23	25/03/26	2,74	2,74	1-MO.	87,0	238,38	16,6	1,5	MEC.	
1	6	CTC9006	3C	A	18/03/23	25/03/26	10,51	10,51	1-MO.	87,0	914,37	16,6	1,5	MEC.	
1	7	CTC9006	3C	A	17/03/23	25/03/26	3,71	3,71	1-MO.	87,0	322,77	16,6	1,5	MEC.	
1	8	CTC9006	3C	A	16/03/23	25/03/26	5,95	5,95	1-MO.	87,0	517,65	16,6	1,5	MEC.	
1	9	CTC9006	3C	A	20/03/23	25/03/26	1,46	1,46	1-MO.	87,0	127,02	16,6	1,5	MEC.	
1	10	CTC9006	3C	B	15/03/23	25/03/26	14,64	14,64	1-MO.	87,0	1.273,68	16,6	1,5	MEC.	
1	11	CTC9006	3C	A	20/03/23	25/03/26	1,71	1,71	1-MO.	87,0	148,77	16,6	1,5	MEC.	
Total/Média (1 / 45 · S.SEB.TAQUARUÇU)							50,89	50,89		87,0	4.427,43				

N: 7707971.426
E: 370347.7445
LAT: −20°43'25.4819" (−20.72374498)
LONG: −46°14'43.9429" (−46.24553970)

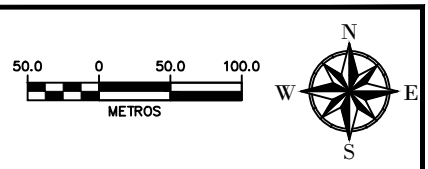

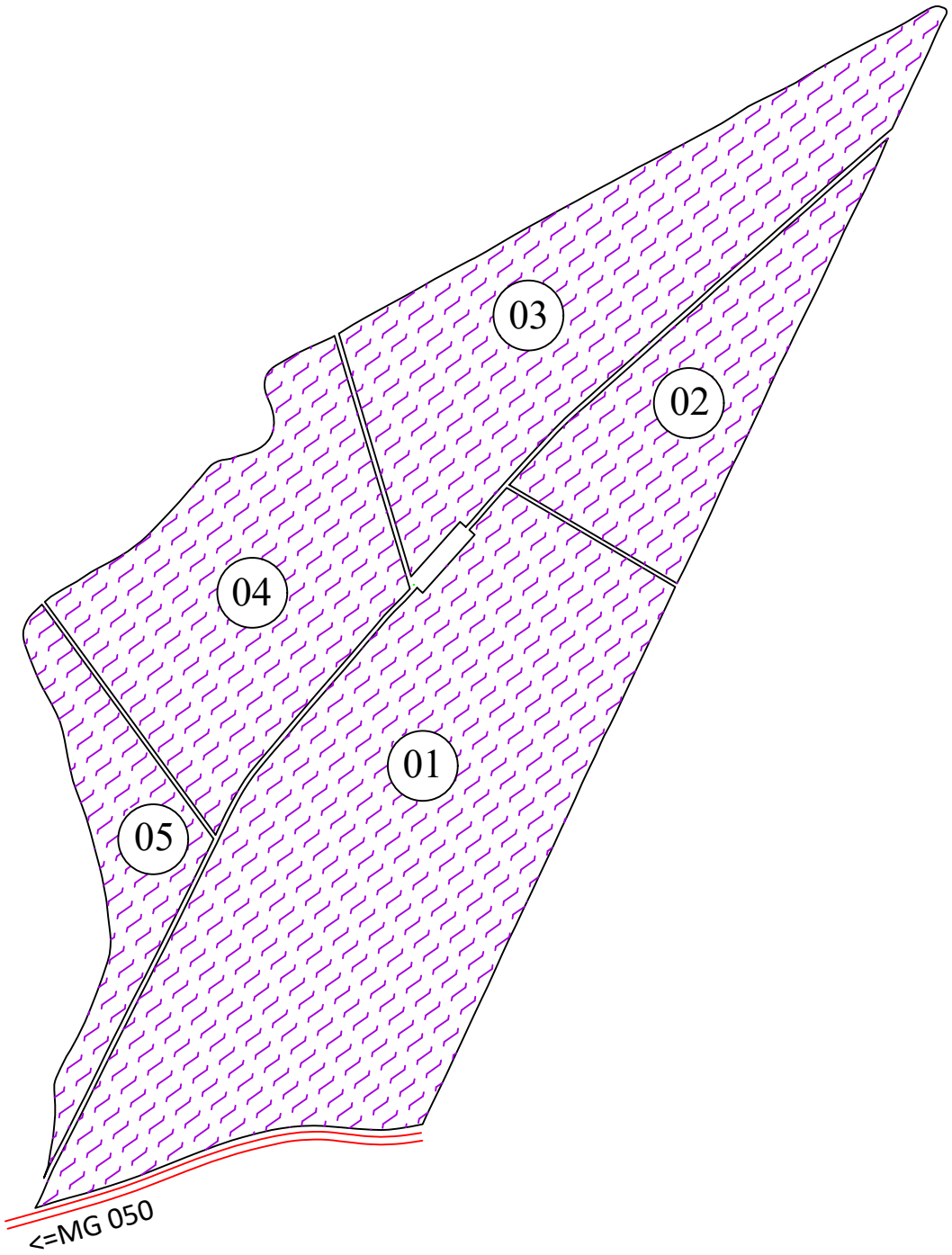

CTC - 9007

TABELA DE VARIEDADE	
VARIEDADE	ÁREA
CTC9007	76,64
Total Geral	**76,64**

IPIRANGA AGROINDUSTRIAL	PROJETO CADERNO DE MAPA 26'27	DATA 29/01/2026	ESCALA 1:5000	TOPÓGRAFO CRISTIAN
	FAZENDA 046 - SITIO TRÊS BARRAS	MUNICÍPIO SAO JOSÉ DA BARRA		ÁREA (ha) 76,64
	PROPRIETÁRIO AGRO PECUÁRIA VALE DO RIO GRANDE	UNIDADE IPIRANGA PASSOS - MG		ÁREA (ha) 046

Caderno de Mapas

Bloco	Talhao	Variedade	Estágio de Corte	Amb. Prod.	Data Plantio	Último Corte	Área (ha)	Estimativas Área (ha)	Finalid	Produt.	Prod. Total	Dist.	Esp.	Tipo Corte	Experimento
1 · REG 1			**46 · ST.TRES BARRAS**				**IPIRANGA AGROINDUSTRIAL S.A**								
1	1	CTC9007	3C	A	02/04/23	20/06/25	32,36	32,36	1-MO.	70,0	2.265,20	26	1,5	MEC.	
1	2	CTC9007	3C	A	01/04/23	20/06/25	8,20	8,20	1-MO.	70,0	574,00	26	1,5	MEC.	
1	3	CTC9007	3C	A	31/03/23	20/06/25	16,82	16,82	1-MO.	70,0	1.177,40	26	1,5	MEC.	
1	4	CTC9007	3C	A	01/04/23	20/06/25	13,87	13,87	1-MO.	70,0	970,90	26	1,5	MEC.	
1	5	CTC9007	3C	A	01/04/23	20/06/25	5,39	5,39	1-MO.	70,0	377,30	26	1,5	MEC.	
Total/Média (1 / 46 · ST.TRES BARRAS)							76,64	76,64		70,0	5.364,80				

N: 7707971.426
E: 370347.7445
LAT: −20°43'25.4819" (−20.72374498)
LONG: −46°14'43.9429" (−46.24553970)

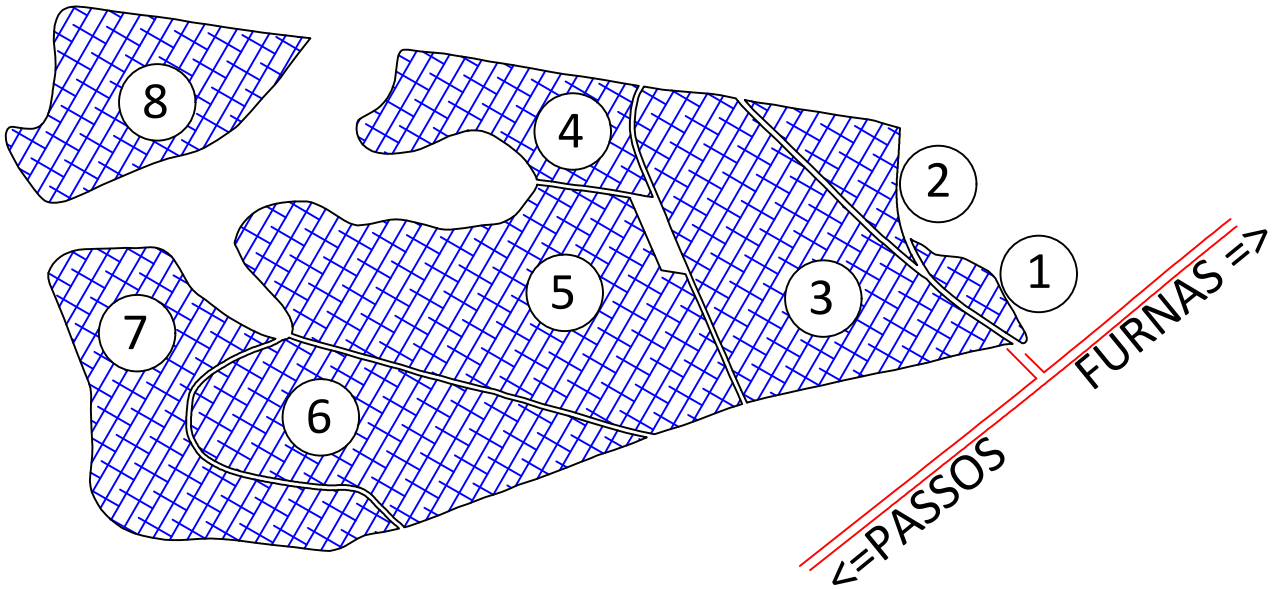

RB 98-7935

TABELA DE VARIEDADE	
VARIEDADE	ÁREA
RB987935	32,48
Total Geral	**32,48**

IPIRANGA AGROINDUSTRIAL

PROJETO: CADERNO DE MAPA 26'27	DATA: 30/01/2026	ESCALA: 1:5000	TOPÓGRAFO: CRISTIAN
FAZENDA: 047 - SITIO BARRA TRES LAGOAS	MUNICÍPIO: SAO JOSÉ DA BARRA		ÁREA (ha): 32,48
PROPRIETÁRIO: AGRO PECUÁRIA VALE DO RIO GRANDE	UNIDADE: IPIRANGA PASSOS - MG		ÁREA (ha): 047

Caderno de Mapas

Bloco	Talhao	Variedade	Estágio de Corte	Amb. Prod.	Data Plantio	Último Corte	Área (ha)	Estimativas Área (ha)	Finalid	Produt.	Prod. Total	Dist.	Esp.	Tipo Corte	Experimento
1 · REG 1			**47 · ST.B.TRES LAGOA**				**IPIRANGA AGROINDUSTRIAL S.A**								
1	1	RB987935	4C	B	04/11/22	11/09/25	0,42	0,42	1-MO.	77,0	32,34	27,2	1,5	MEC.	
1	2	RB987935	4C	B	04/11/22	11/09/25	1,08	1,08	1-MO.	77,0	83,16	27,2	1,5	MEC.	
1	3	RB987935	4C	B	04/11/22	11/09/25	6,19	6,19	1-MO.	77,0	476,63	27,2	1,5	MEC.	
1	4	RB987935	4C	B	07/11/22	11/09/25	2,70	2,70	1-MO.	77,0	207,90	27,2	1,5	MEC.	
1	5	RB987935	4C	B	06/11/22	11/09/25	8,33	8,33	1-MO.	77,0	641,41	27,2	1,5	MEC.	
1	6	RB987935	4C	C	04/11/22	11/09/25	4,98	4,98	1-MO.	77,0	383,46	27,2	1,5	MEC.	
1	7	RB987935	4C	B	04/11/22	11/09/25	5,04	5,04	1-MO.	77,0	388,08	27,2	1,5	MEC.	
1	8	RB987935	4C	B	05/11/22	11/09/25	3,74	3,74	1-MO.	77,0	287,98	27,2	1,5	MEC.	
Total/Média (1 / 47 · ST.B.TRES LAGOA)							32,48	32,48		77,0	2.500,96				

N: 7707107.665
E: 357185.5340
LAT: −20°43'50.1112" (−20.73058644)
LONG: −46°22'19.1702" (−46.37199171)

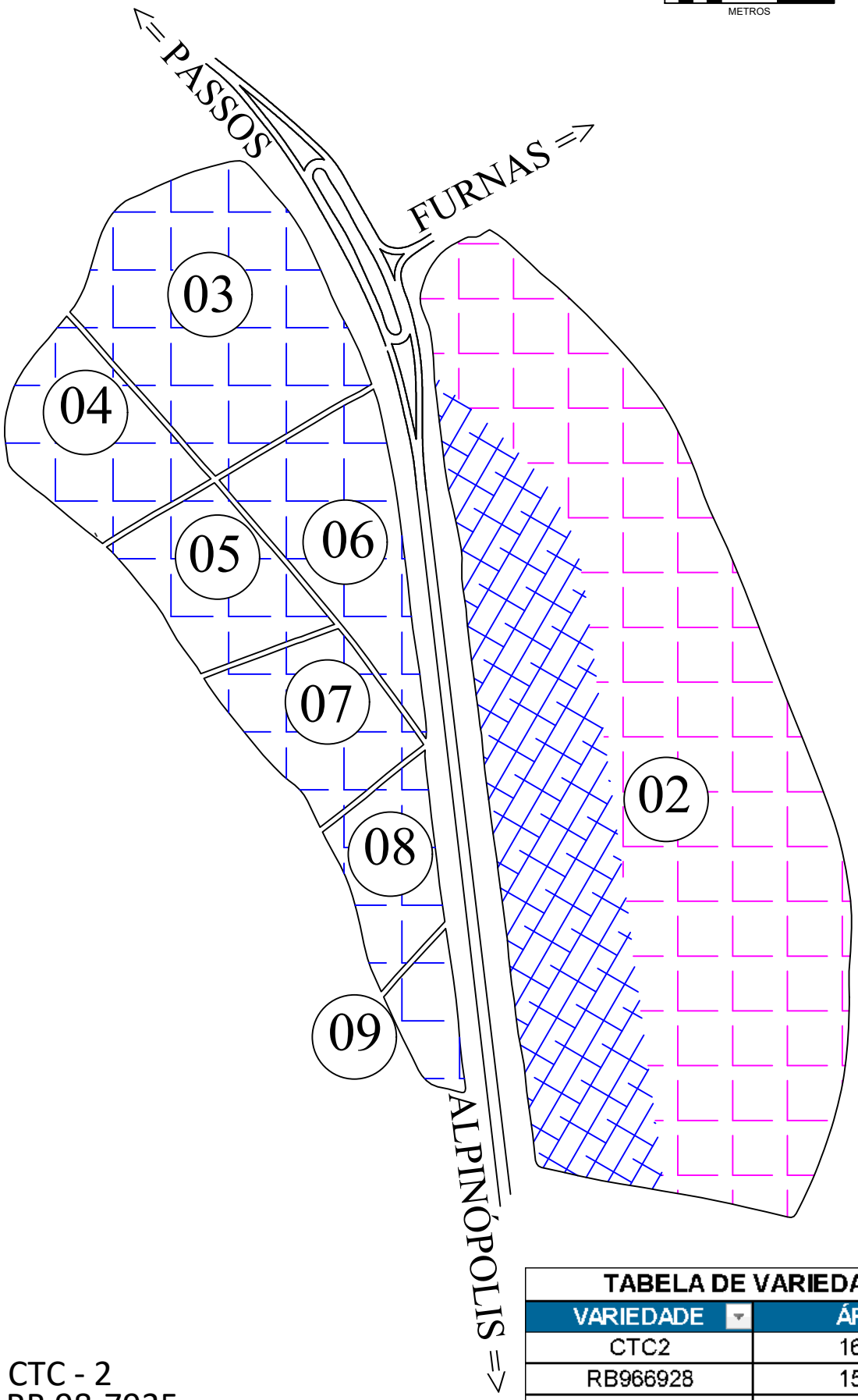

CTC - 2
RB 98-7935
RB 96-6928

TABELA DE VARIEDADE

VARIEDADE	ÁREA
CTC2	16,20
RB966928	15,88
RB987935	8,17
Total Geral	**40,25**

IPIRANGA AGROINDUSTRIAL

PROJETO: CADERNO DE MAPA 26'27	DATA: 30/01/2026	ESCALA: 1:5000	TOPÓGRAFO: CRISTIAN
FAZENDA: 048-SITIO NOSSA SENHORA DO CARMO	MUNICÍPIO: ALPINOLOLIS - MG		ÁREA (ha): 40,25
PROPRIETÁRIO: ITAIQUARA ALIMENTOS S.A	UNIDADE: IPIRANGA PASSOS		ÁREA (ha): 048

Caderno de Mapas

Bloco	Talhao	Variedade	Estágio de Corte	Amb. Prod.	Data Plantio	Último Corte	Área (ha)	Estimativas Área (ha)	Finalid	Produt.	Prod. Total	Dist.	Esp.	Tipo Corte	Experimento
1 · REG 1			**48 · ST.N.S.CARMO**				**IPIRANGA AGROINDUSTRIAL S.A**								
1	2	RB966928	4C	B	05/04/22	02/09/25	15,88	15,88	1-MO.	30,0	476,40	26,4	1,5	MEC.	
1	2	RB987935	4C	B	05/04/22	02/09/25	8,17	8,17	1-MO.	30,0	245,10	26,4	1,5	MEC.	
1	3	CTC2	4C	B	09/03/22	02/09/25	5,14	5,14	1-MO.	70,0	359,80	26,4	1,5	MEC.	
1	4	CTC2	4C	B	09/03/22	02/09/25	2,26	2,26	1-MO.	70,0	158,20	26,4	1,5	MEC.	
1	5	CTC2	4C	B	09/03/22	02/09/25	1,97	1,97	1-MO.	70,0	137,90	26,4	1,5	MEC.	
1	6	CTC2	4C	B	09/03/22	02/09/25	2,70	2,70	1-MO.	70,0	189,00	26,4	1,5	MEC.	
1	7	CTC2	4C	B	09/03/22	02/09/25	2,01	2,01	1-MO.	70,0	140,70	26,4	1,5	MEC.	
1	8	CTC2	4C	B	09/03/22	02/09/25	1,45	1,45	1-MO.	70,0	101,50	26,4	1,5	MEC.	
1	9	CTC2	4C	B	09/03/22	02/09/25	0,67	0,67	1-MO.	70,0	46,90	26,4	1,5	MEC.	
Total/Média (1 / 48 · ST.N.S.CARMO)							40,25	40,25		46,1	1.855,50				

N: 7707971.426
E: 370347.7445
LAT: -20°43'25.4819" (-20.72374498)
LONG: -46°14'43.9429" (-46.24553970)

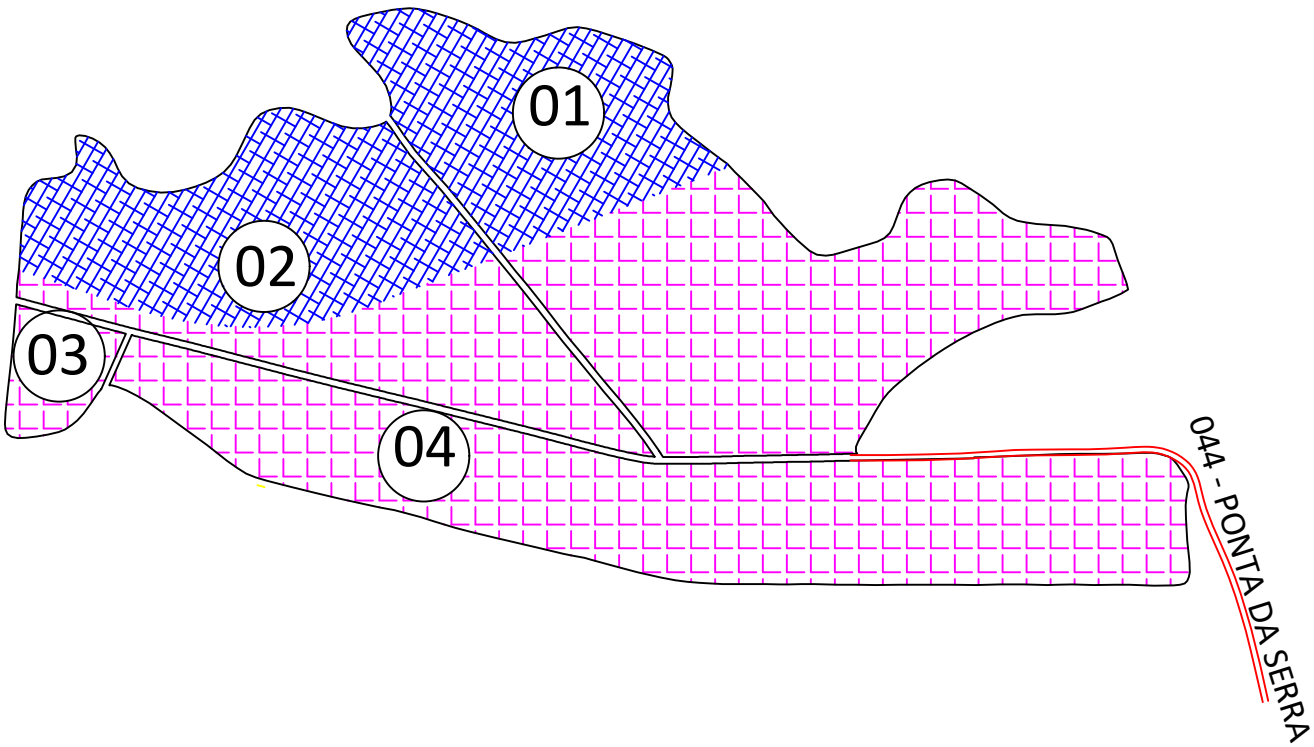

RB 96-6928

RB 98-7935

TABELA DE VARIEDADE	
VARIEDADE	ÁREA
RB966928	21,02
RB987935	9,22
Total Geral	**30,24**

IPIRANGA AGROINDUSTRIAL

PROJETO: CADERNO DE MAPA 26'27	DATA: 30/01/2026	ESCALA: 1:5000	TOPÓGRAFO: CRISTIAN
FAZENDA: 049 - SÍTIO PÉ DA SERRA	MUNICÍPIO: SAO JOSÉ DA BARRA		ÁREA (ha): 30,24
PROPRIETÁRIO: AGRO PECUÁRIA VALE DO RIO GRANDE	UNIDADE: IPIRANGA PASSOS - MG		ÁREA (ha): 049

Caderno de Mapas

Bloco	Talhao	Variedade	Estágio de Corte	Amb. Prod.	Data Plantio	Último Corte	Área (ha)	Estimativas Área (ha)	Finalid	Produt.	Prod. Total	Dist.	Esp.	Tipo Corte	Experimento
1 · REG 1			**49 · ST.PE DA SERRA**				**IPIRANGA AGROINDUSTRIAL S.A**								
1	1	RB966928	4C	A	01/03/22	05/09/25	7,79	7,79	1-MO.	74,0	576,46	39,4	1,5	MEC.	
1	1	RB987935	4C	A	01/03/22	05/09/25	4,10	4,10	1-MO.	74,0	303,40	39,4	1,5	MEC.	
1	2	RB966928	4C	A	02/03/22	05/09/25	3,08	3,08	1-MO.	74,0	227,92	39,4	1,5	MEC.	
1	2	RB987935	4C	A	02/03/22	05/09/25	5,12	5,12	1-MO.	74,0	378,88	39,4	1,5	MEC.	
1	3	RB966928	4C	A	02/03/22	05/09/25	0,83	0,83	1-MO.	74,0	61,42	39,4	1,5	MEC.	
1	4	RB966928	4C	A	03/03/22	05/09/25	9,32	9,32	1-MO.	74,0	689,68	39,4	1,5	MEC.	
Total/Média (1 / 49 · ST.PE DA SERRA)							30,24	30,24		74,0	2.237,76				

N: 7705406.790
E: 359395.3836
LAT: -20°44'46.0286" (-20.74611906)
LONG: -46°21'3.2718" (-46.35090884)

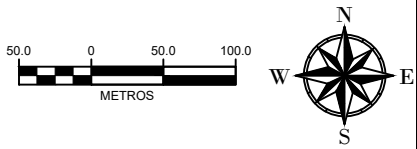

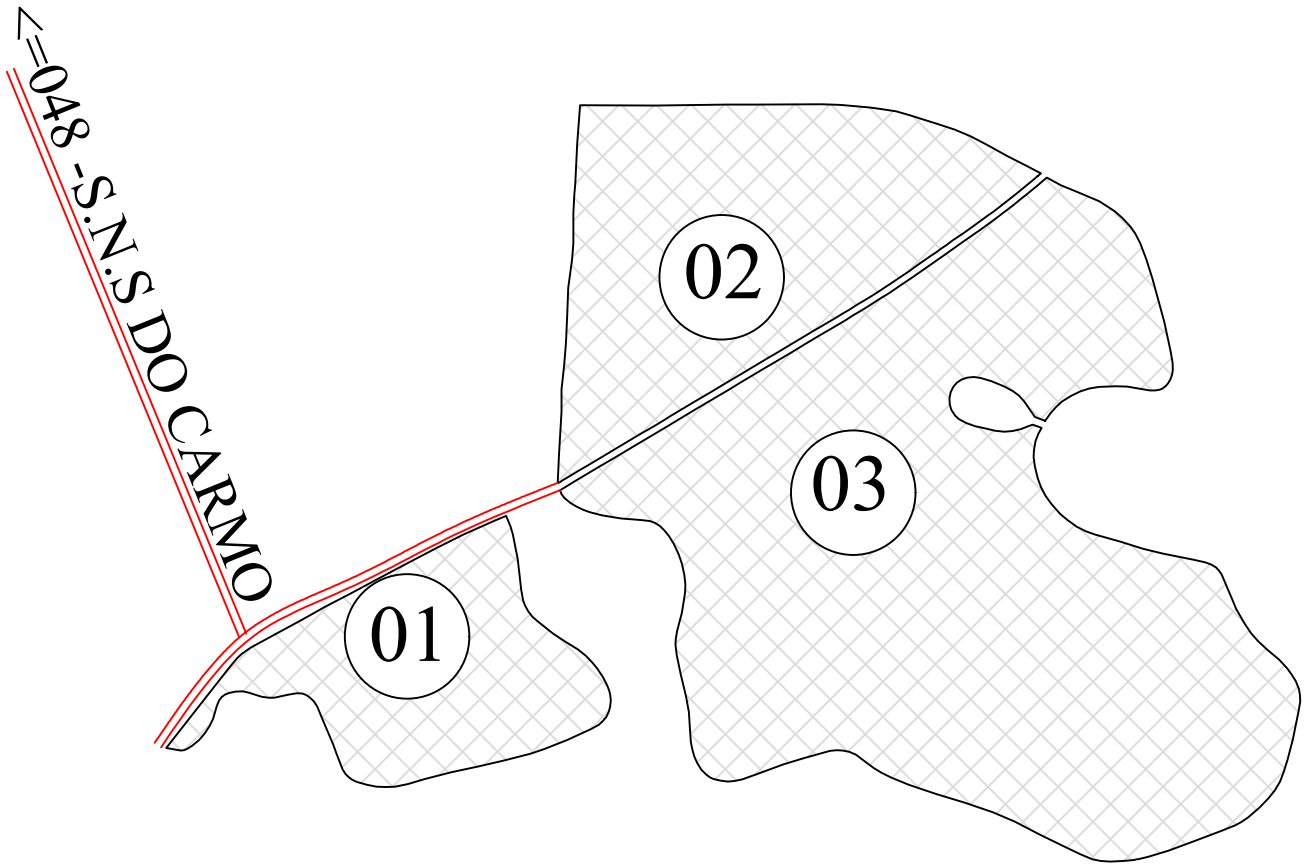

CTC - 4

TABELA DE VARIEDADE	
VARIEDADE	ÁREA
CTC4	17,47
Total Geral	**17,47**

IPIRANGA AGROINDUSTRIAL

PROJETO: CADERNO DE MAPA 26'27	DATA: 30/01/2026	ESCALA: 1:5000	TOPÓGRAFO: CRISTIAN
FAZENDA: 050 - SITIO SÃO BENTO	MUNICÍPIO: ALPINOPOLIS		ÁREA (ha): 17,47
PROPRIETÁRIO: ITAIQUARA ALIMENTOS S.A	UNIDADE: IPIRANGA PASSOS MG		ÁREA (ha): 050

Caderno de Mapas

Bloco	Talhao	Variedade	Estágio de Corte	Amb. Prod.	Data Plantio	Último Corte	Área (ha)	Estimativas Área (ha)	Finalid	Produt.	Prod. Total	Dist.	Esp.	Tipo Corte	Experimento
1 · REG 1			**50 · ST.S.BENTO**				**IPIRANGA AGROINDUSTRIAL S.A**								
1	1	CTC4	4C	CB	09/03/22	03/09/25	2,38	2,38	1-MO.	70,0	166,60	30	1,5	MEC.	
1	2	CTC4	4C	CB	09/03/22	03/09/25	4,21	4,21	1-MO.	70,0	294,70	30	1,5	MEC.	
1	3	CTC4	4C	CB	09/03/22	03/09/25	10,88	10,88	1-MO.	70,0	761,60	30	1,5	MEC.	
Total/Média (1 / 50 · ST.S.BENTO)							17,47	17,47		70,0	1.222,90				

N: 7705406.790
E: 359395.3836
LAT: -20°44'46.0286" (-20.74611906)
LONG: -46°21'3.2718" (-46.35090884)

50.0 0 50.0 100.0
METROS

N
W E
S

53 - TRES LAGOAS

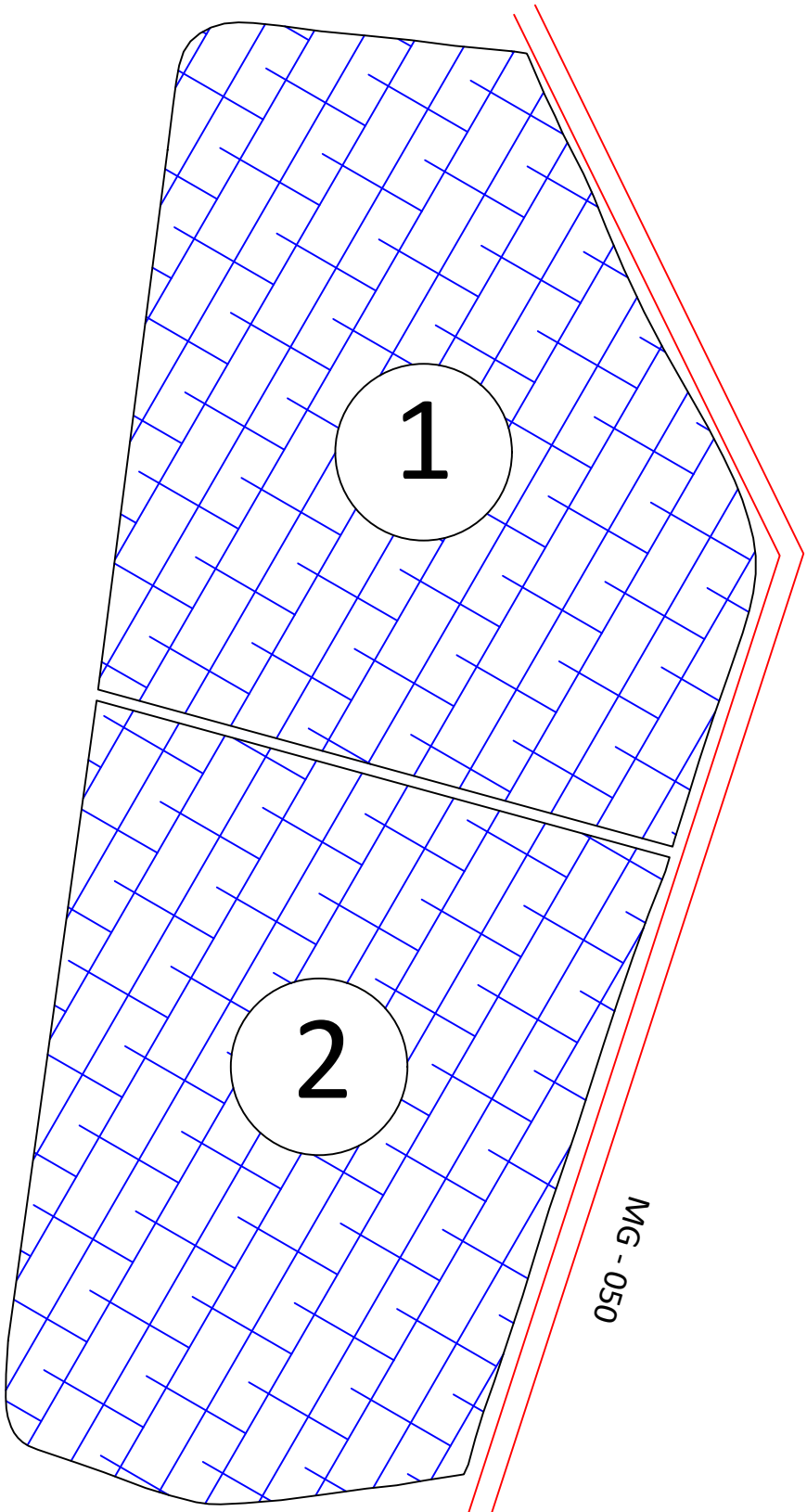

RB 98-7935

TABELA DE VARIEDADE	
VARIEDADE	ÁREA
RB987935	15,76
Total Geral	**15,76**

IPIRANGA AGROINDUSTRIAL

PROJETO: CADERNO DE MAPA 26'27	DATA: 04/03/2026	ESCALA: 1:5000	TOPÓGRAFO: CRISTIAN
FAZENDA: 051 - SITIO TRÊS LAGOAS	MUNICÍPIO: ALPINOPOLIS		ÁREA (ha): 15,76
PROPRIETÁRIO: ITAIQUARA ALIMENTOS S.A	UNIDADE: IPIRANGA PASSOS MG		CÓDIGO: 051

Caderno de Mapas

Bloco	Talhao	Variedade	Estágio de Corte	Amb. Prod.	Data Plantio	Último Corte	Área (ha)	Estimativas Área (ha)	Finalid	Produt.	Prod. Total	Dist.	Esp.	Tipo Corte	Experimento
1 · REG 1			**51 · ST.TRES LAGOAS**				**IPIRANGA AGROINDUSTRIAL S.A**								
1	1	RB987935	4C	A	16/11/22	12/09/25	8,00	8,00	1-MO.	70,0	560,00	28,2	1,5	MEC.	
1	2	RB987935	4C	A	11/11/22	12/09/25	7,76	7,76	1-MO.	70,0	543,20	28,2	1,5	MEC.	
Total/Média (1 / 51 · ST.TRES LAGOAS)							15,76	15,76		70,0	1.103,20				

N: 7700645.525
E: 342376.5056
LAT: −20°47'15.9518" (−20.78776440)
LONG: −46°30'53.1564" (−46.51476568)

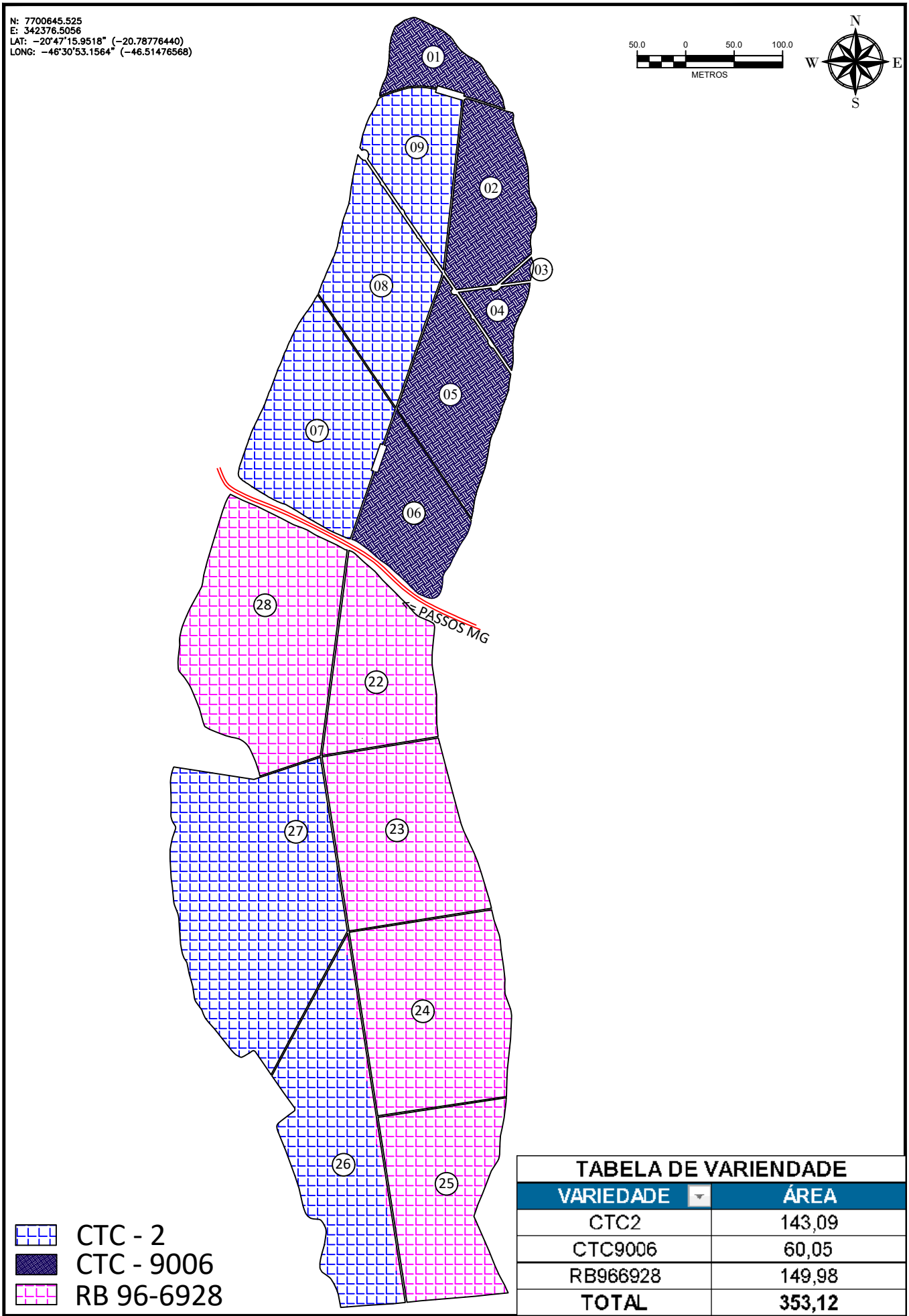

TABELA DE VARIENDADE

VARIEDADE	ÁREA
CTC2	143,09
CTC9006	60,05
RB966928	149,98
TOTAL	**353,12**

IPIRANGA AGROINDUSTRIAL

PROJETO: CADERNO DE MAPA 26'27	DATA: 04/03/2026	ESCALA: 1:5000	TOPÓGRAFO: CRISTIAN
FAZENDA: 052 - TRES BARRAS	MUNICÍPIO: PASSOS - MG		ÁREA (ha): 353,12
PROPRIETÁRIO: ITAIQUARA ALIMENTOS S.A	UNIDADE: IPIRANGA PASSOS - MG		CÓDIGO: 052

Caderno de Mapas

Bloco	Talhao	Variedade	Estágio de Corte	Amb. Prod.	Data Plantio	Último Corte	Área (ha)	Estimativas Área (ha)	Finalid	Produt.	Prod. Total	Dist.	Esp.	Tipo Corte	Experimento
1 · REG 1			**52 · TRES BARRAS**				**IPIRANGA AGROINDUSTRIAL S.A**								
1	1	CTC9006	FORM	BA	14/01/26		7,29	0,00	.		0,00	27	1,5	N/D	
1	2	CTC9006	FORM	BA	14/01/26		16,12	0,00	.		0,00	27	1,5	N/D	
1	3	CTC9006	FORM	BA	14/01/26		0,45	0,00	.		0,00	27	1,5	N/D	
1	4	CTC9006	FORM	BA	14/01/26		3,54	0,00	.		0,00	27	1,5	N/D	
1	5	CTC9006	FORM	B	14/01/26		17,93	0,00	.		0,00	27	1,5	N/D	
1	6	CTC9006	FORM	BA	14/01/26		14,72	0,00	.		0,00	27	1,5	N/D	
1	7	CTC2	FORM	BA	14/01/26		27,02	0,00	.		0,00	27	1,5	N/D	
1	8	CTC2	FORM	BA	14/01/26		19,97	0,00	.		0,00	27	1,5	N/D	
1	9	CTC2	FORM	BA	14/01/26		13,79	0,00	.		0,00	27	1,5	N/D	
1	22	RB966928	4C	BA	24/12/21	07/07/25	20,27	20,27	1-MO.	68,0	1.378,36	27	1,5	MEC.	
1	23	RB966928	4C	BA	14/12/21	07/07/25	28,90	28,90	1-MO.	68,0	1.965,20	27	1,5	MEC.	
1	24	RB966928	4C	BA	10/12/21	07/07/25	33,67	33,67	1-MO.	80,0	2.693,60	27	1,5	MEC.	
1	25	RB966928	4C	BA	09/12/21	07/07/25	24,23	24,23	1-MO.	65,0	1.574,95	27	1,5	MEC.	
1	26	CTC2	5C	BA	03/12/21	07/07/25	31,09	31,09	1-MO.	65,0	2.020,85	27	1,5	MEC.	
1	26	RB966928	5C	BA	03/12/21	07/07/25	1,97	1,97	1-MO.	65,0	128,05	27	1,5	MEC.	
1	27	CTC2	5C	BA	06/12/21	07/07/25	51,22	51,22	1-MO.	65,0	3.329,30	27	1,5	MEC.	
1	28	RB966928	4C	BA	21/12/21	07/07/25	40,94	40,94	1-MO.	65,0	2.661,10	27	1,5	MEC.	
Total/Média (1 / 52 · TRES BARRAS)							353,12	232,29		67,8	15.751,41				

N: 7713220.737
E: 356104.0041
LAT: -20°40'31.0151" (-20.67528197)
LONG: -46°22'54.7538" (-46.38187605)

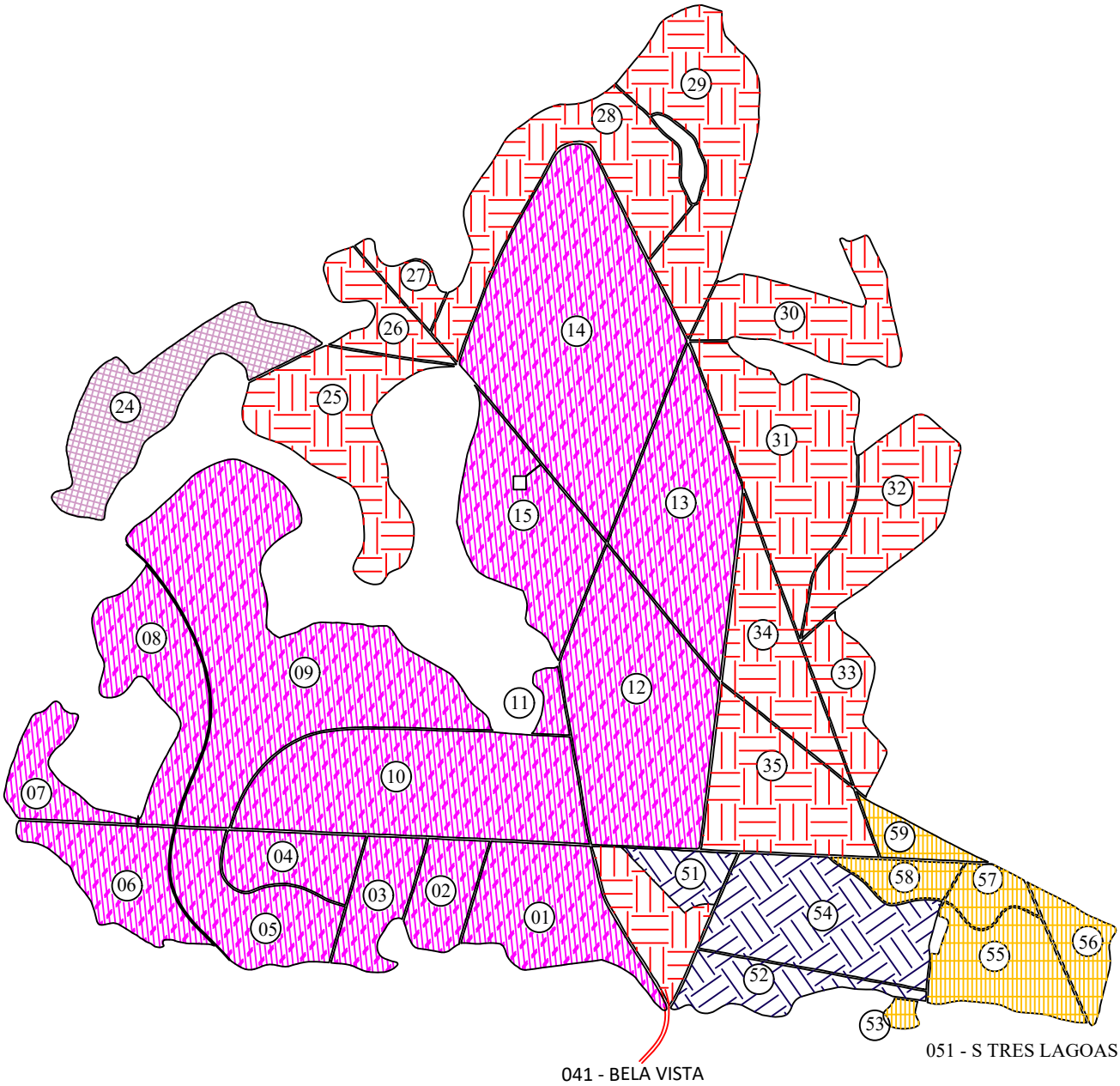

CTC - 9006
CTC-2994
CTC - 9002
RB 98-5476
IAC CTC 07-7207

TABELA DE VARIEDADE

VARIEDADE	ÁREA
CTC2994	208,02
CTC9002	120,84
CTC9006	23,31
IACCTC07-7207	12,80
RB985476	19,94
Total Geral	**384,91**

IPIRANGA
AGRO INDUSTRIAL

PROJETO: CADERNO DE MAPA 26'27	DATA: 04/03/2026	ESCALA: 1:5000	TOPÓGRAFO: CRISTIAN
FAZENDA: 053 - TRÊS LAGOAS	MUNICÍPIO: ALPINÓPOLIS		ÁREA (ha): 384,91
PROPRIETÁRIO: AGRO PRCUARIA V. DO R. GRANDE	UNIDADE: IPIRANGA PASSOS		CÓDIGO: 053

Caderno de Mapas

Bloco	Talhao	Variedade	Estágio de Corte	Amb. Prod.	Data Plantio	Último Corte	Área (ha)	Estimativas Área (ha)	Finalid	Produt.	Prod. Total	Dist.	Esp.	Tipo Corte	Experimento
1 · REG 1			**53 · TRES LAGOAS**				**IPIRANGA AGROINDUSTRIAL S.A**								
1	1	CTC2994	3C	A	13/03/23	20/08/25	11,56	11,56	1-MO.	85,0	982,60	30,6	1,5	MEC.	
1	2	CTC2994	3C	A	14/03/23	20/08/25	4,57	4,57	1-MO.	85,0	388,45	30,6	1,5	MEC.	
1	3	CTC2994	3C	A	14/03/23	20/08/25	5,14	5,14	1-MO.	85,0	436,90	30,6	1,5	MEC.	
1	4	CTC2994	3C	A	15/03/23	20/08/25	5,43	5,43	1-MO.	85,0	461,55	30,6	1,5	MEC.	
1	5	CTC2994	3C	A	16/03/23	20/08/25	9,32	9,32	1-MO.	85,0	792,20	30,6	1,5	MEC.	
1	6	CTC2994	3C	A	26/04/23	20/08/25	8,60	8,60	1-MO.	85,0	731,00	30,6	1,5	MEC.	
1	7	CTC2994	3C	A	19/03/23	20/08/25	4,52	4,52	1-MO.	85,0	384,20	30,6	1,5	MEC.	
1	8	CTC2994	3C	A	19/03/23	20/08/25	10,18	10,18	1-MO.	85,0	865,30	30,6	1,5	MEC.	
1	9	CTC2994	3C	A	16/03/23	20/08/25	34,90	34,90	1-MO.	85,0	2.966,50	30,6	1,5	MEC.	
1	10	CTC2994	3C	A	15/03/23	20/08/25	23,59	23,59	1-MO.	85,0	2.005,15	30,6	1,5	MEC.	
1	11	CTC2994	3C	A	15/03/23	20/08/25	1,17	1,17	1-MO.	85,0	99,45	30,6	1,5	MEC.	
1	12	CTC2994	3C	A	05/03/23	20/08/25	23,57	23,57	1-MO.	85,0	2.003,45	30,6	1,5	MEC.	
1	13	CTC2994	3C	A	03/03/23	20/08/25	16,81	16,81	1-MO.	85,0	1.428,85	30,6	1,5	MEC.	
1	14	CTC2994	3C	A	09/03/23	20/08/25	34,98	34,98	1-MO.	85,0	2.973,30	30,6	1,5	MEC.	
1	15	CTC2994	3C	A	10/03/23	20/08/25	13,68	13,68	1-MO.	85,0	1.162,80	30,6	1,5	MEC.	
1	24	IACCTC07-7207	FORM	A	30/04/26		12,80	0,00	.		0,00	30,6	1,5	N/D	
1	25	CTC9002	4C	A	13/04/22	20/08/25	13,75	13,75	1-MO.	77,0	1.058,75	30,6	1,5	MEC.	
1	26	CTC9002	4C	A	13/04/22	20/08/25	4,44	4,44	1-MO.	77,0	341,88	30,6	1,5	MEC.	
1	27	CTC9002	4C	A	13/04/22	20/08/25	2,03	2,03	1-MO.	77,0	156,31	30,6	1,5	MEC.	
1	28	CTC9002	4C	A	12/04/22	20/08/25	14,75	14,75	1-MO.	77,0	1.135,75	30,6	1,5	MEC.	
1	29	CTC9002	4C	A	12/04/22	20/08/25	15,45	15,45	1-MO.	77,0	1.189,65	30,6	1,5	MEC.	
1	30	CTC9002	4C	A	12/04/22	20/08/25	9,67	9,67	1-MO.	77,0	744,59	30,6	1,5	MEC.	
1	31	CTC9002	4C	A	12/04/22	20/08/25	17,05	17,05	1-MO.	77,0	1.312,85	30,6	1,5	MEC.	
1	32	CTC9002	4C	B	12/04/22	20/08/25	10,64	10,64	1-MO.	77,0	819,28	30,6	1,5	MEC.	
1	33	CTC9002	4C	A	12/04/22	20/08/25	5,14	5,14	1-MO.	77,0	395,78	30,6	1,5	MEC.	
1	34	CTC9002	4C	A	08/04/22	20/08/25	9,47	9,47	1-MO.	77,0	729,19	30,6	1,5	MEC.	
1	35	CTC9002	4C	A	10/04/22	20/08/25	12,68	12,68	1-MO.	77,0	976,36	30,6	1,5	MEC.	
1	51	CTC9002	4C	A	09/04/22	20/08/25	5,77	5,77	1-MO.	77,0	444,29	30,6	1,5	MEC.	
1	51	CTC9006	4C	A	09/04/22	20/08/25	2,97	2,97	1-MO.	77,0	228,69	30,6	1,5	MEC.	
1	52	CTC9006	4C	CB	09/04/22	20/08/25	5,35	5,35	1-MO.	62,0	331,70	30,6	1,5	MEC.	
1	53	RB985476	4C	CB	09/04/22	20/08/25	0,58	0,58	1-MO.	62,0	35,96	30,6	1,5	MEC.	
1	54	CTC9006	4C	CB	08/04/22	20/08/25	14,99	14,99	1-MO.	62,0	929,38	30,6	1,5	MEC.	
1	55	RB985476	4C	CB	07/04/22	20/08/25	8,24	8,24	1-MO.	62,0	510,88	30,6	1,5	MEC.	
1	56	RB985476	4C	CB	09/04/22	20/08/25	3,63	3,63	1-MO.	62,0	225,06	30,6	1,5	MEC.	
1	57	RB985476	4C	A	08/04/22	20/08/25	2,58	2,58	1-MO.	62,0	159,96	30,6	1,5	MEC.	
1	58	RB985476	4C	A	09/04/22	20/08/25	2,62	2,62	1-MO.	62,0	162,44	30,6	1,5	MEC.	
1	59	RB985476	4C	A	08/04/22	20/08/25	2,29	2,29	1-MO.	62,0	141,98	30,6	1,5	MEC.	
Total/Média (1 / 53 · TRES LAGOAS)							384,91	372,11		79,8	29.712,43				

N: 7728460.142
E: 319170.7391
LAT: −20°32'3.9678" (−20.53443550)
LONG: −46°44'5.2471" (−46.73479085)

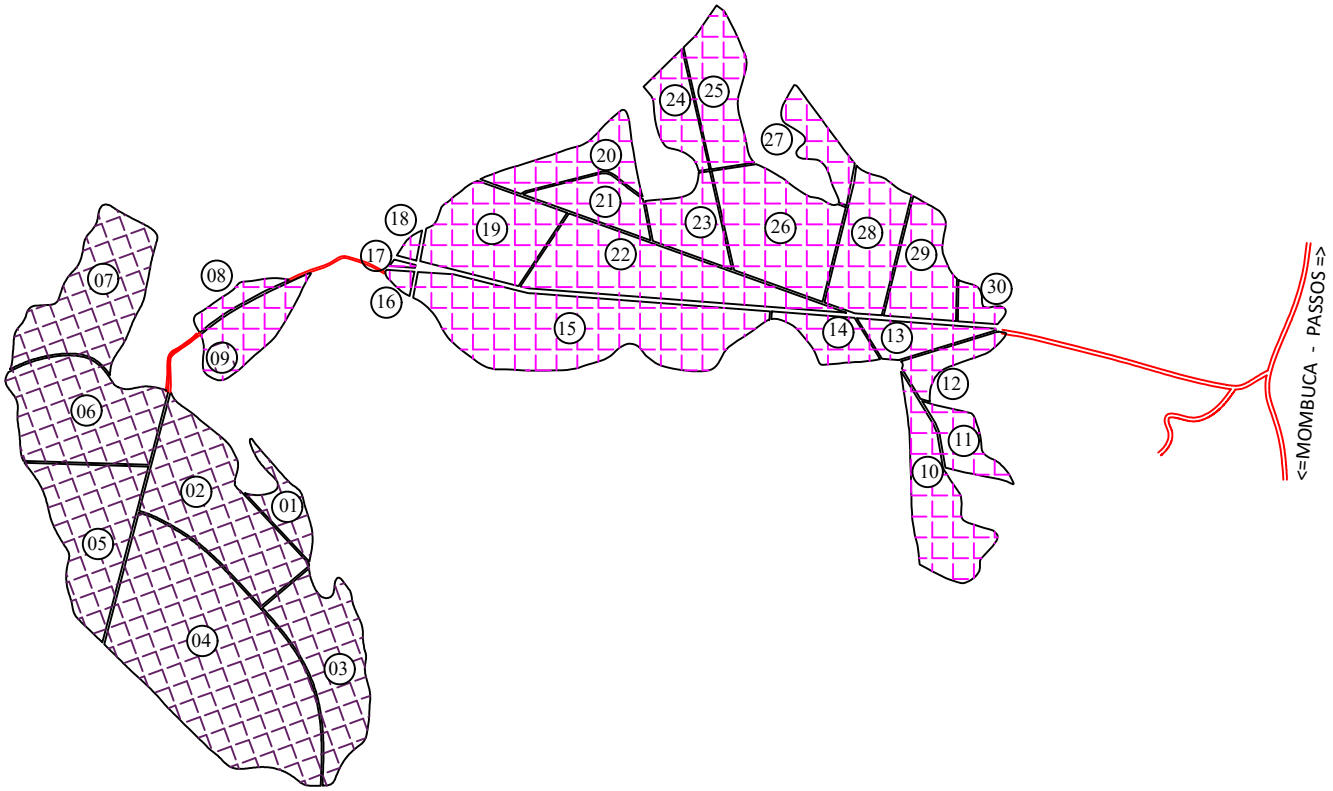

RB 96-6928

RB 97-5952

TABELA DE VARIEDADE	
VARIEDADE	ÁREA
RB966928	86,38
RB975952	68,07
Total Geral	**154,45**

IPIRANGA AGROINDUSTRIAL

PROJETO: CADERNO DE MAPA 26'27	DATA: 04/03/2026	ESCALA: 1:5000	TOPÓGRAFO: CRISTIAN
FAZENDA: 054 - VERA CRUZ	MUNICÍPIO: PASSOS MG		ÁREA (ha): 154,45
PROPRIETÁRIO: CIA AÇUCAREIRA RIO GRANDA	UNIDADE: IPIRANGA PASSOS		CÓDIGO: 054

Caderno de Mapas

Bloco	Talhao	Variedade	Estágio de Corte	Amb. Prod.	Data Plantio	Último Corte	Área (ha)	Estimativas Área (ha)	Finalid	Produt.	Prod. Total	Dist.	Esp.	Tipo Corte	Experimento
1 · REG 1			**54 · VERA CRUZ**				**IPIRANGA AGROINDUSTRIAL S.A**								
1	1	RB975952	3C	B	17/04/23	06/06/25	1,91	1,91	1-MO.	72,0	137,52	23	1,5	MEC.	
1	2	RB975952	3C	A	13/04/23	06/06/25	10,30	10,30	1-MO.	72,0	741,60	23	1,5	MEC.	
1	3	RB975952	3C	B	15/04/23	06/06/25	7,54	7,54	1-MO.	72,0	542,88	23	1,5	MEC.	
1	4	RB975952	3C	A	09/04/23	06/06/25	22,63	22,63	1-MO.	72,0	1.629,36	23	1,5	MEC.	
1	5	RB975952	3C	A	10/04/23	06/06/25	7,87	7,87	1-MO.	72,0	566,64	23	1,5	MEC.	
1	6	RB975952	3C	A	14/04/23	06/06/25	9,20	9,20	1-MO.	72,0	662,40	23	1,5	MEC.	
1	7	RB975952	3C	B	21/04/23	06/06/25	8,62	8,62	1-MO.	72,0	620,64	23	1,5	MEC.	
1	8	RB966928	3C	B	24/04/23	22/05/26	0,98	0,98	1-MO.	80,0	78,40	23	1,5	MEC.	
1	9	RB966928	3C	B	24/04/23	22/05/26	3,44	3,44	1-MO.	80,0	275,20	23	1,5	MEC.	
1	10	RB966928	3C	BA	09/04/23	22/05/26	5,60	5,60	1-MO.	80,0	448,00	23	1,5	MEC.	
1	11	RB966928	3C	BA	08/04/23	22/05/26	2,10	2,10	1-MO.	80,0	168,00	23	1,5	MEC.	
1	12	RB966928	3C	BA	08/04/23	22/05/26	1,61	1,61	1-MO.	80,0	128,80	23	1,5	MEC.	
1	13	RB966928	3C	BA	06/04/23	22/05/26	2,14	2,14	1-MO.	80,0	171,20	23	1,5	MEC.	
1	14	RB966928	3C	BA	10/04/23	22/05/26	2,15	2,15	1-MO.	80,0	172,00	23	1,5	MEC.	
1	15	RB966928	3C	CB	25/04/23	22/05/26	14,65	14,65	1-MO.	80,0	1.172,00	23	1,5	MEC.	
1	16	RB966928	3C	CB	24/04/23	22/05/26	0,31	0,31	1-MO.	80,0	24,80	23	1,5	MEC.	
1	17	RB966928	3C	CB	24/04/23	22/05/26	0,08	0,08	1-MO.	80,0	6,40	23	1,5	MEC.	
1	18	RB966928	3C	CB	25/04/23	22/05/26	0,26	0,26	1-MO.	80,0	20,80	23	1,5	MEC.	
1	19	RB966928	3C	CB	24/05/23	22/05/26	6,62	6,62	1-MO.	80,0	529,60	23	1,5	MEC.	
1	20	RB966928	3C	A	26/04/23	22/05/26	3,56	3,56	1-MO.	80,0	284,80	23	1,5	MEC.	
1	21	RB966928	3C	A	26/04/23	22/05/26	2,77	2,77	1-MO.	80,0	221,60	23	1,5	MEC.	
1	22	RB966928	3C	BA	23/04/23	22/05/26	8,81	8,81	1-MO.	80,0	704,80	23	1,5	MEC.	
1	23	RB966928	3C	BA	23/04/23	22/05/26	3,14	3,14	1-MO.	80,0	251,20	23	1,5	MEC.	
1	24	RB966928	3C	A	21/04/23	22/05/26	2,66	2,66	1-MO.	80,0	212,80	23	1,5	MEC.	
1	25	RB966928	3C	A	19/04/23	22/05/26	4,70	4,70	1-MO.	80,0	376,00	23	1,5	MEC.	
1	26	RB966928	3C	BA	08/04/23	22/05/26	8,15	8,15	1-MO.	80,0	652,00	23	1,5	MEC.	
1	27	RB966928	3C	A	06/04/23	22/05/26	2,24	2,24	1-MO.	80,0	179,20	23	1,5	MEC.	
1	28	RB966928	3C	A	06/04/23	22/05/26	5,45	5,45	1-MO.	80,0	436,00	23	1,5	MEC.	
1	29	RB966928	3C	A	06/04/23	22/05/26	4,10	4,10	1-MO.	80,0	328,00	23	1,5	MEC.	
1	30	RB966928	3C	A	06/04/23	22/05/26	0,86	0,86	1-MO.	80,0	68,80	23	1,5	MEC.	
Total/Média (1 / 54 · VERA CRUZ)							154,45	154,45		76,5	11.811,44				

N: 7728460.142
E: 319170.7391
LAT: −20°32'3.9678" (−20.53443550)
LONG: −46°44'5.2471" (−46.73479085)

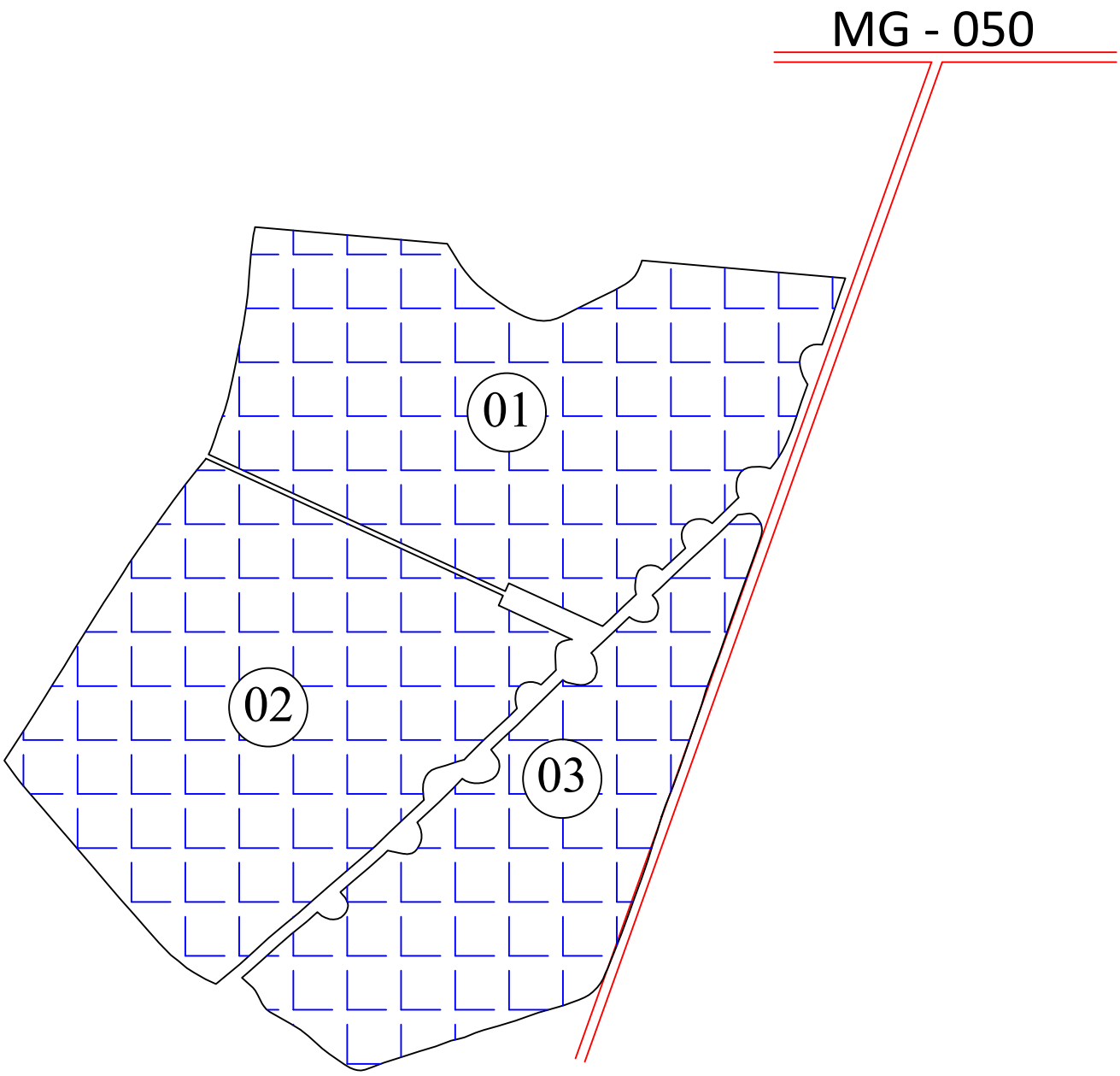

CTC - 2

TABELA DE VARIEDADE	
VARIEDADE	ÁREA
CTC2	43,52
Total Geral	**43,52**

IPIRANGA AGROINDUSTRIAL

PROJETO: CADERNO DE MAPA 26'27	DATA: 04/03/2026	ESCALA: 1:5000	TOPÓGRAFO: CRISTIAN
FAZENDA: 060 - BATATAIS	MUNICÍPIO: PASSOS MG		ÁREA (ha): 43,52
PROPRIETÁRIO: CIA AÇUCAREIRA RIO GRANDA	UNIDADE: IPIRANGA PASSOS		CÓDIGO: 060

Caderno de Mapas

Bloco	Talhao	Variedade	Estágio de Corte	Amb. Prod.	Data Plantio	Último Corte	Área (ha)	Estimativas Área (ha)	Finalid	Produt.	Prod. Total	Dist.	Esp.	Tipo Corte	Experimento
1 · REG 1			**60 · BATATAIS**				**IPIRANGA AGROINDUSTRIAL S.A**								
1	1	CTC2	3C	A	07/11/22	07/05/26	16,27	16,27	1-MO.	85,0	1.382,95	23	1,5	MEC.	
1	2	CTC2	4C	BA	07/11/22	07/05/26	16,32	16,32	1-MO.	85,0	1.387,20	23	1,5	MEC.	
1	3	CTC2	4C	A	07/11/22	07/05/26	10,93	10,93	1-MO.	85,0	929,05	23	1,5	MEC.	
Total/Média (1 / 60 · BATATAIS)							43,52	43,52		85,0	3.699,20				

N: 7709632.500
E: 325290.6607
LAT: −20°42'18.2415" (−20.70506707)
LONG: −46°40'40.7052" (−46.67797368)

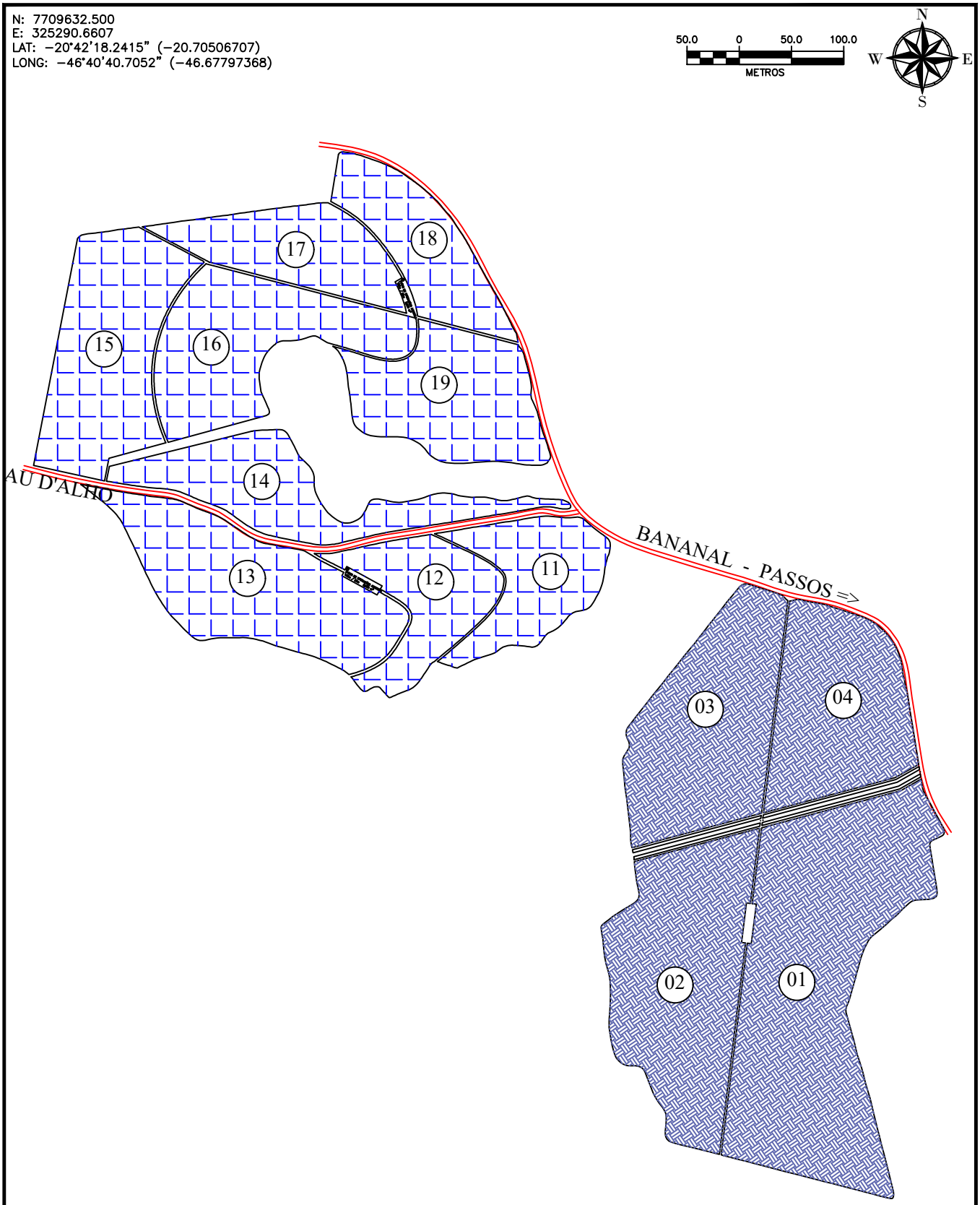

CTC - 2
CTC - 9003

TABELA DE VARIEDADE	
VARIEDADE	ÁREA
CTC2	107,99
CTC9003	86,40
Total Geral	**194,39**

IPIRANGA AGROINDUSTRIAL	PROJETO: CADERNO DE MAPA 26'27	DATA: 04/03/2026	ESCALA: 1:5000	TOPÓGRAFO: CRISTIAN
	FAZENDA: 062 - TAGUAUNA I	MUNICÍPIO: PASSOS MG		ÁREA (ha): 194,39
	PROPRIETÁRIO:	UNIDADE: IPIRANGA PASSOS		CÓDIGO: 062

Caderno de Mapas

Bloco	Talhao	Variedade	Estágio de Corte	Amb. Prod.	Data Plantio	Último Corte	Área (ha)	Estimativas Área (ha)	Finalid	Produt.	Prod. Total	Dist.	Esp.	Tipo Corte	Experimento
1 · REG 1			**62 · TAGUAUNA I**				**IPIRANGA AGROINDUSTRIAL S.A**								
1	1	CTC9003	2C	BA	10/11/23	22/04/26	33,41	33,41	1-MO.	77,0	2.572,57	26	1,5	MEC.	
1	2	CTC9003	2C	BA	12/11/23	22/04/26	20,90	20,90	1-MO.	77,0	1.609,30	26	1,5	MEC.	
1	3	CTC9003	2C	B	11/11/23	22/04/26	17,50	17,50	1-MO.	77,0	1.347,50	26	1,5	MEC.	
1	4	CTC9003	2C	B	11/11/23	22/04/26	14,59	14,59	1-MO.	77,0	1.123,43	26	1,5	MEC.	
1	11	CTC2	3C	A	04/11/22	19/04/26	8,92	8,92	1-MO.	80,0	713,60	26	1,5	MEC.	
1	12	CTC2	3C	CB	04/11/22	19/04/26	8,50	8,50	1-MO.	80,0	680,00	26	1,5	MEC.	
1	13	CTC2	3C	C	03/11/22	19/04/26	17,19	17,19	1-MO.	80,0	1.375,20	26	1,5	MEC.	
1	14	CTC2	4C	CB	28/10/22	19/04/26	11,74	11,74	1-MO.	80,0	939,20	26	1,5	MEC.	
1	15	CTC2	3C	C	31/10/22	19/04/26	15,89	15,89	1-MO.	80,0	1.271,20	26	1,5	MEC.	
1	16	CTC2	3C	C	27/10/22	19/04/26	14,57	14,57	1-MO.	80,0	1.165,60	26	1,5	MEC.	
1	17	CTC2	3C	C	28/10/22	19/04/26	9,24	9,24	1-MO.	80,0	739,20	26	1,5	MEC.	
1	18	CTC2	3C	C	27/10/22	19/04/26	9,12	9,12	1-MO.	80,0	729,60	26	1,5	MEC.	
1	19	CTC2	3C	C	27/10/22	19/04/26	12,82	12,82	1-MO.	80,0	1.025,60	26	1,5	MEC.	
Total/Média (1 / 62 · TAGUAUNA I)							194,39	194,39		78,7	15.292,00				

N: 7708422.582
E: 336944.5378
LAT: −20°43'1.3786" (−20.71704960)
LONG: −46°33'58.3768" (−46.56621578)

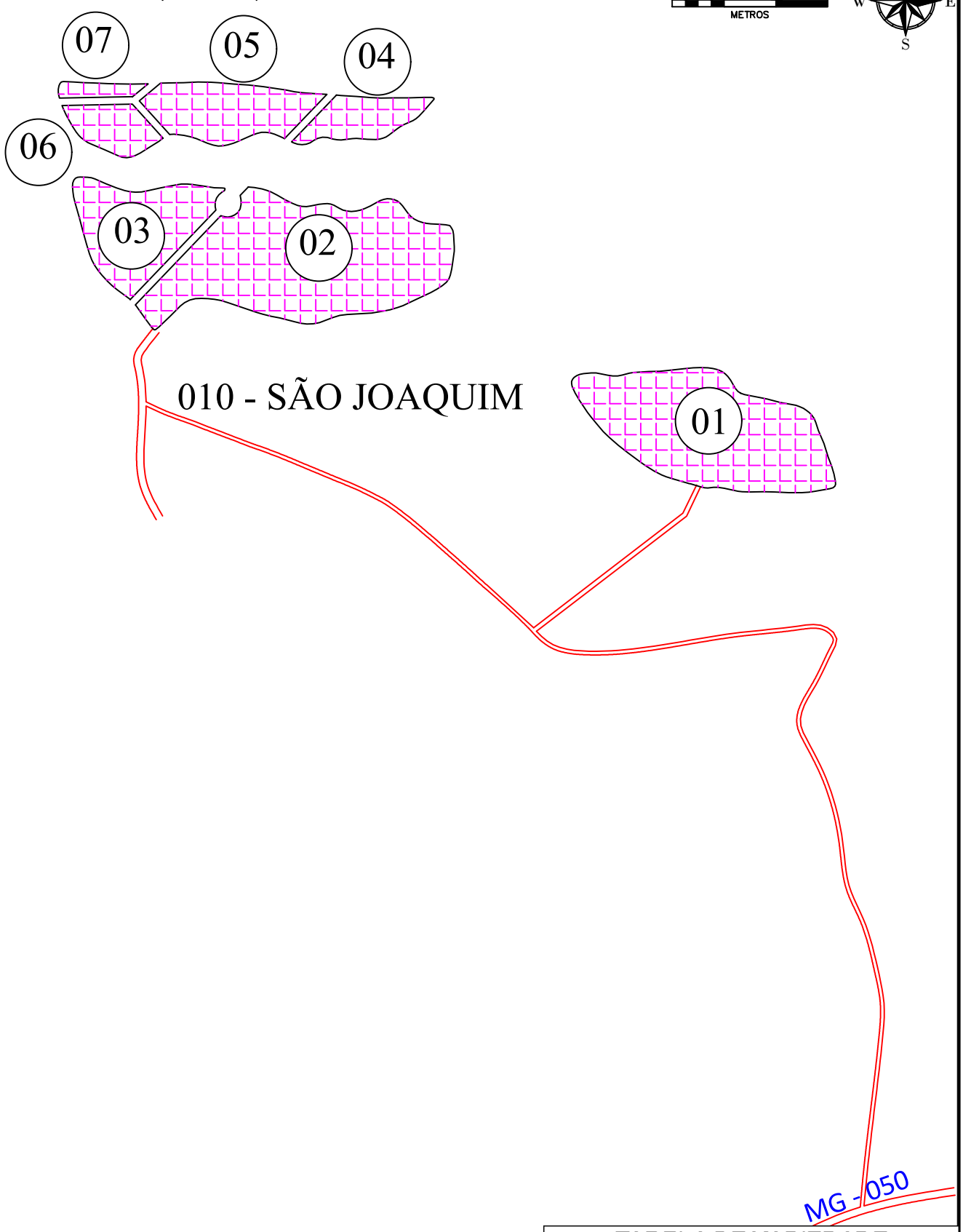

RB 96-6928

TABELA DE VARIEDADE	
VARIEDADE	ÁREA
RB966928	14,27
Total Geral	**14,27**

IPIRANGA AGROINDUSTRIAL	PROJETO: CADERNO DE MAPA 25'26	DATA: 28-04-2025	ESCALA: 1:5000	TOPÓGRAFO: CRISTIAN
	FAZENDA: 066 - SERRINHA	MUNICÍPIO: PASSOS MG		ÁREA (ha): 14,27
	PROPRIETÁRIO: IPIRANGA AGROINDUSTRIAL	UNIDADE: IPIRANGA PASSOS		CÓDIGO: 066

Caderno de Mapas

Bloco	Talhao	Variedade	Estágio de Corte	Amb. Prod.	Data Plantio	Último Corte	Área (ha)	Estimativas Área (ha)	Finalid	Produt.	Prod. Total	Dist.	Esp.	Tipo Corte	Experimento
1 · REG 1			**66 · SERRINHA**					**IPIRANGA AGROINDUSTRIAL S.A**							
1	1	RB966928	3C	CB	20/01/23	25/03/26	4,10	4,10	1-MO.	85,0	348,50	11,9	1,5	MEC.	
1	2	RB966928	3C	B	20/01/23	25/03/26	5,15	5,15	1-MO.	85,0	437,75	11,9	1,5	MEC.	
1	3	RB966928	3C	B	20/01/23	25/03/26	1,93	1,93	1-MO.	85,0	164,05	11,9	1,5	MEC.	
1	4	RB966928	3C	B	20/01/23	25/03/26	0,76	0,76	1-MO.	85,0	64,60	11,9	1,5	MEC.	
1	5	RB966928	3C	B	20/01/23	25/03/26	1,48	1,48	1-MO.	85,0	125,80	11,9	1,5	MEC.	
1	6	RB966928	3C	B	20/01/23	25/03/26	0,64	0,64	1-MO.	85,0	54,40	11,9	1,5	MEC.	
1	7	RB966928	3C	B	20/01/23	25/03/26	0,21	0,21	1-MO.	85,0	17,85	11,9	1,5	MEC.	
Total/Média (1 / 66 · SERRINHA)							14,27	14,27		85,0	1.212,95				

N: 7721265.760
E: 321450.5030
LAT: −20°35'58.6783" (−20.59963286)
LONG: −46°42'49.1654" (−46.71365705)

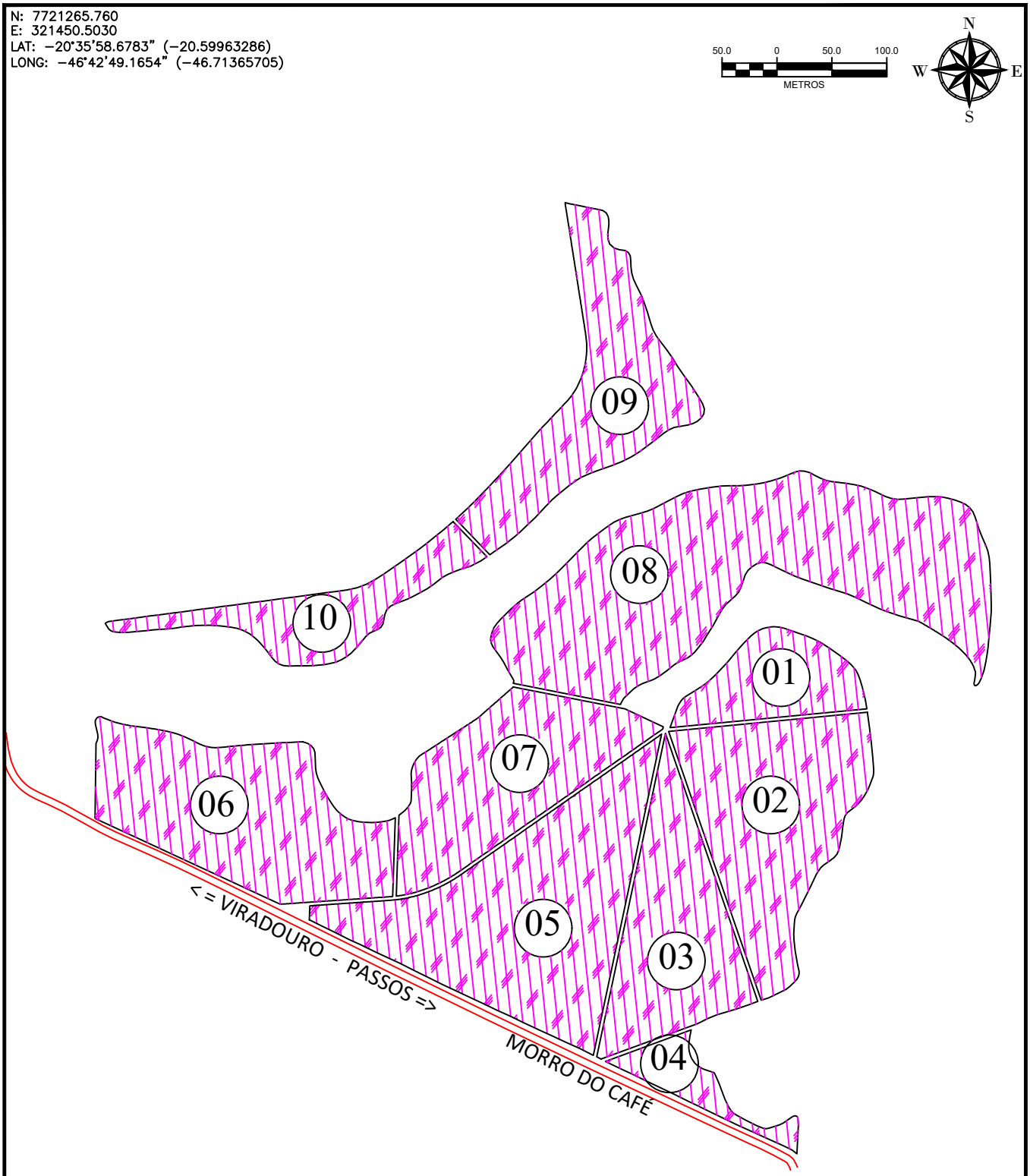

CTC -2994

TABELA DE VARIEDADE	
VARIEDADE	ÁREA
CTC2994	54,87
Total Geral	**54,87**

IPIRANGA AGROINDUSTRIAL	PROJETO: CADERNO DE MAPA 26'27	DATA: 04/03/2026	ESCALA: 1:5000	TOPÓGRAFO: CRISTIAN
	FAZENDA: 067 - SÃO SEBASTIÃO	MUNICÍPIO: PASSOS MG		ÁREA (ha): 54,87
	PROPRIETÁRIO: ITAIQUARA ALIMENTOS S.A	UNIDADE: IPIRANGA PASSOS		CÓDIGO: 067

Caderno de Mapas

Bloco	Talhao	Variedade	Estágio de Corte	Amb. Prod.	Data Plantio	Último Corte	Área (ha)	Estimativas Área (ha)	Finalid	Produt.	Prod. Total	Dist.	Esp.	Tipo Corte	Experimento
1 · REG 1			**67 · S.SEBASTIAO**				**IPIRANGA AGROINDUSTRIAL S.A**								
1	1	CTC2994	3C	BA	28/03/23	30/10/25	2,29	2,29	1-MO.	83,0	190,07	18	1,5	MEC.	
1	2	CTC2994	3C	BA	27/03/23	30/10/25	6,20	6,20	1-MO.	83,0	514,60	18	1,5	MEC.	
1	3	CTC2994	3C	BA	23/03/23	30/10/25	4,70	4,70	1-MO.	83,0	390,10	18	1,5	MEC.	
1	4	CTC2994	3C	BA	25/03/23	30/10/25	1,05	1,05	1-MO.	83,0	87,15	18	1,5	MEC.	
1	5	CTC2994	3C	A	25/03/23	30/10/25	8,51	8,51	1-MO.	83,0	706,33	18	1,5	MEC.	
1	6	CTC2994	3C	A	25/03/23	30/10/25	6,84	6,84	1-MO.	83,0	567,72	18	1,5	MEC.	
1	7	CTC2994	3C	A	25/03/23	30/10/25	5,22	5,22	1-MO.	83,0	433,26	18	1,5	MEC.	
1	8	CTC2994	3C	B	23/03/23	30/10/25	12,00	12,00	1-MO.	83,0	996,00	18	1,5	MEC.	
1	9	CTC2994	3C	B	25/03/23	30/10/25	5,29	5,29	1-MO.	83,0	439,07	18	1,5	MEC.	
1	10	CTC2994	3C	B	27/03/23	30/10/25	2,77	2,77	1-MO.	83,0	229,91	18	1,5	MEC.	
Total/Média (1 / 67 · S.SEBASTIAO)							54,87	54,87		83,0	4.554,21				

N: 7728460.142
E: 319170.7391
LAT: −20°32'3.9678" (−20.53443550)
LONG: −46°44'5.2471" (−46.73479085)

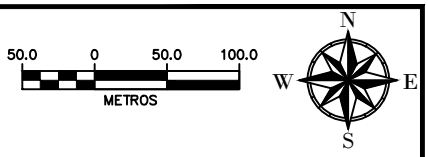

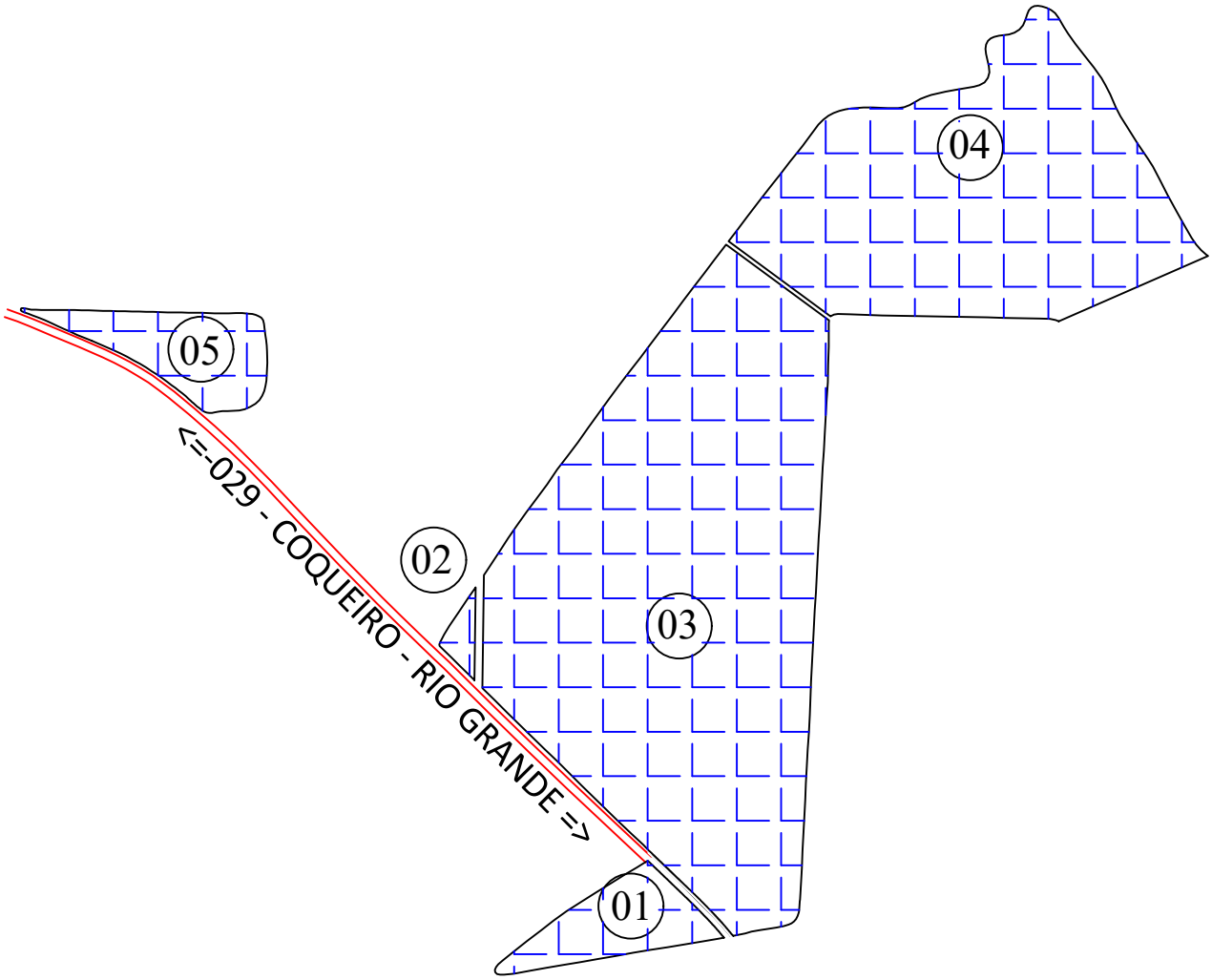

CTC - 2

TABELA DE VARIEDADE	
VARIEDADE	ÁREA
CTC2	40,98
Total Geral	**40,98**

IPIRANGA AGROINDUSTRIAL

PROJETO: CADERNO DE MAPA 26'27	DATA: 04/03/2026	ESCALA: 1:5000	TOPÓGRAFO: CRISTIAN
FAZENDA: 069 - BARRINHA	MUNICÍPIO: PASSOS MG		ÁREA (ha): 40,98
PROPRIETÁRIO: IPIRANGA AGROINDUSTRIAL	UNIDADE: IPIRANGA PASSOS		CÓDIGO: 069

Caderno de Mapas

Bloco	Talhao	Variedade	Estágio de Corte	Amb. Prod.	Data Plantio	Último Corte	Área (ha)	Estimativas Área (ha)	Finalid	Produt.	Prod. Total	Dist.	Esp.	Tipo Corte	Experimento
1 · REG 1			**69 · BARRINHA II**				**IPIRANGA AGROINDUSTRIAL S.A**								
1	1	CTC2	3C	BA	23/02/23	12/09/25	1,76	1,76	1-MO.	60,0	105,60	29	1,5	MEC.	
1	2	CTC2	3C	BA	23/02/23	12/09/25	0,26	0,26	1-MO.	60,0	15,60	29	1,5	MEC.	
1	3	CTC2	3C	BA	23/02/23	12/09/25	23,52	23,52	1-MO.	60,0	1.411,20	29	1,5	MEC.	
1	4	CTC2	3C	A	23/02/23	12/09/25	13,37	13,37	1-MO.	60,0	802,20	29	1,5	MEC.	
1	5	CTC2	3C	A	23/02/23	12/09/25	2,07	2,07	1-MO.	60,0	124,20	29	1,5	MEC.	
Total/Média (1 / 69 · BARRINHA II)							40,98	40,98		60,0	2.458,80				

N: 7728460.142
E: 319170.7391
LAT: −20°32'3.9678" (−20.53443550)
LONG: −46°44'5.2471" (−46.73479085)

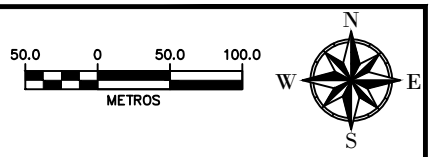

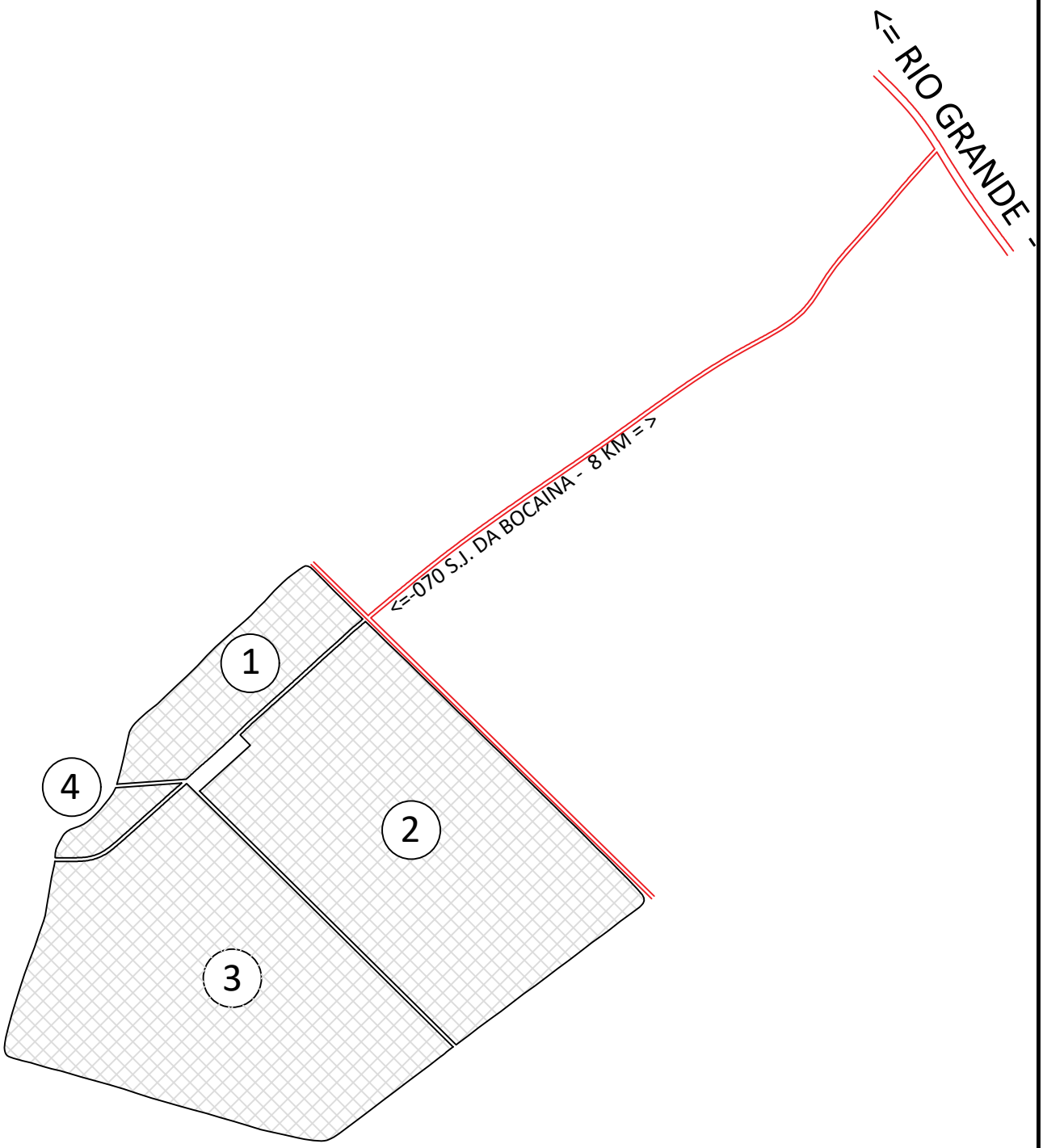

CTC - 4

TABELA DE VARIEDADE	
VARIEDADE	ÁREA
CTC4	39,07
Total Geral	**39,07**

IPIRANGA AGROINDUSTRIAL

PROJETO: CADERNO DE MAPA 26'27	DATA: 04/03/2026	ESCALA: 1:5000	TOPÓGRAFO: CRISTIAN
FAZENDA: 070-SÃO JOSÉ DA BOCAINA	MUNICÍPIO: PASSOS MG		ÁREA (ha): 39,07
PROPRIETÁRIO:	UNIDADE: IPIRANGA PASSOS		CÓDIGO: 070

Caderno de Mapas

Bloco	Talhao	Variedade	Estágio de Corte	Amb. Prod.	Data Plantio	Último Corte	Área (ha)	Estimativas Área (ha)	Finalid	Produt.	Prod. Total	Dist.	Esp.	Tipo Corte	Experimento
1 · REG 1			**70 · S.JOSE BOCAINA**				**IPIRANGA AGROINDUSTRIAL S.A**								
1	1	CTC4	4C	A	26/10/22	14/11/25	3,86	3,86	1-MO.	80,0	308,80	16	1,5	MEC.	
1	2	CTC4	4C	A	26/10/22	14/11/25	17,25	17,25	1-MO.	80,0	1.380,00	16	1,5	MEC.	
1	3	CTC4	4C	A	25/10/22	14/11/25	17,23	17,23	1-MO.	80,0	1.378,40	16	1,5	MEC.	
1	4	CTC4	4C	A	26/10/22	14/11/25	0,73	0,73	1-MO.	80,0	58,40	16	1,5	MEC.	
Total/Média (1 / 70 · S.JOSE BOCAINA)							39,07	39,07		80,0	3.125,60				

N: 7728460.142
E: 319170.7391
LAT: −20°32'3.9678" (−20.53443550)
LONG: −46°44'5.2471" (−46.73479085)

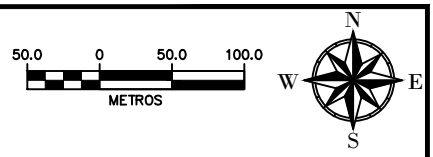

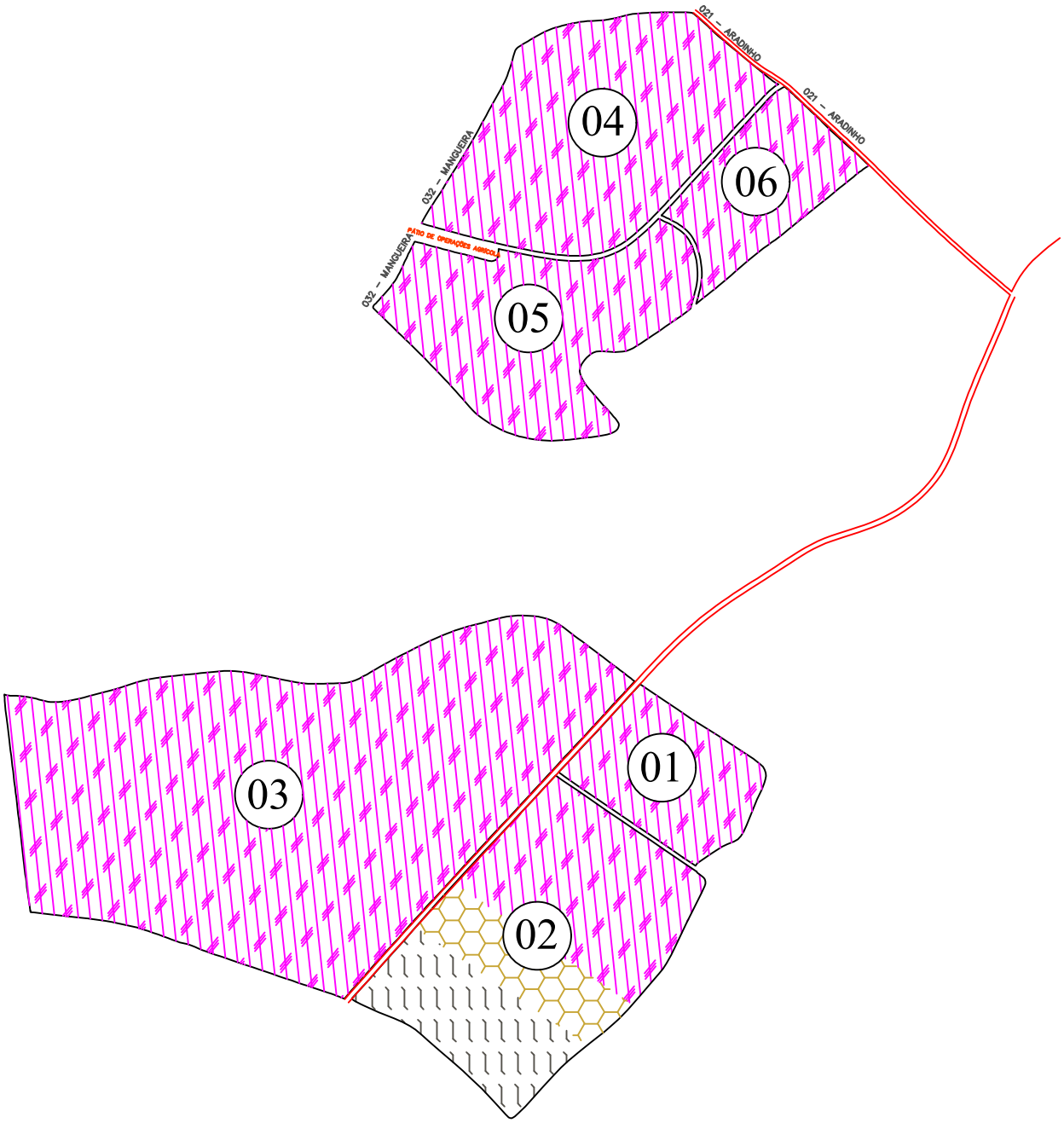

CTC - 9008
RB 12-7825
CTC 02-2994

TABELA DE VARIEDADE

VARIEDADE	ÁREA
CTC2994	42,37
CTC9008	2,59
RB127825	1,73
Total Geral	**46,69**

IPIRANGA AGROINDUSTRIAL

PROJETO: CADERNO DE MAPA 26'27	DATA: 04/03/2026	ESCALA: 1:5000	TOPÓGRAFO: CRISTIAN
FAZENDA: 071 - BARRA DOCE	MUNICÍPIO: PASSOS MG		ÁREA (ha): 46,69
PROPRIETÁRIO:	UNIDADE: IPIRANGA PASSOS		CÓDIGO: 071

Caderno de Mapas

Bloco	Talhao	Variedade	Estágio de Corte	Amb. Prod.	Data Plantio	Último Corte	Área (ha)	Estimativas Área (ha)	Finalid	Produt.	Prod. Total	Dist.	Esp.	Tipo Corte	Experimento
1 · REG 1			**71 · BARRA DOCE II**				**IPIRANGA AGROINDUSTRIAL S.A**								
1	1	CTC2994	2C	B	18/10/23	30/05/25	2,80	2,80	1-MO.	80,0	224,00	28	1,5	MEC.	
1	2	CTC2994	3C	B	17/10/23	02/07/25	4,12	3,63	1-MO.	80,0	290,40	28	1,5	MEC.	
1	2	CTC2994	3C	B	17/10/23	02/07/25	4,12	0,49	2-MU.	70,0	34,30	28	1,5	MEC.	
1	2	CTC9008	3C	B	17/10/23	02/07/25	2,59	2,28	1-MO.	80,0	182,40	28	1,5	MEC.	
1	2	CTC9008	3C	B	17/10/23	02/07/25	2,59	0,31	2-MU.	70,0	21,70	28	1,5	MEC.	
1	2	RB127825	3C	B	17/10/23	02/07/25	1,73	1,53	1-MO.	80,0	122,40	28	1,5	MEC.	
1	2	RB127825	3C	B	17/10/23	02/07/25	1,73	0,20	2-MU.	70,0	14,00	28	1,5	MEC.	
1	3	CTC2994	1C	IN	09/10/25		19,77	19,77	2-MU.	70,0	1.383,90	28	1,5	MEC.	
1	4	CTC2994	1C	IN	09/10/25		7,36	7,36	2-MU.	70,0	515,20	28	1,5	MEC.	
1	5	CTC2994	1C	IN	09/10/25		5,68	5,68	2-MU.	70,0	397,60	28	1,5	MEC.	
1	6	CTC2994	1C	IN	09/10/25		2,64	2,64	2-MU.	70,0	184,80	28	1,5	MEC.	
1	202	A DEFINIR	EXP	IN	01/01/26		5,02	0,00	.		0,00	28	1,5	N/D	
Total/Média (1 / 71 · BARRA DOCE II)							51,71	46,69		72,2	3.370,70				

N: 7703925.213
E: 341382.9768
LAT: −20°45'29.0000" (−20.75805555)
LONG: −46°31'26.4408" (−46.52401134)

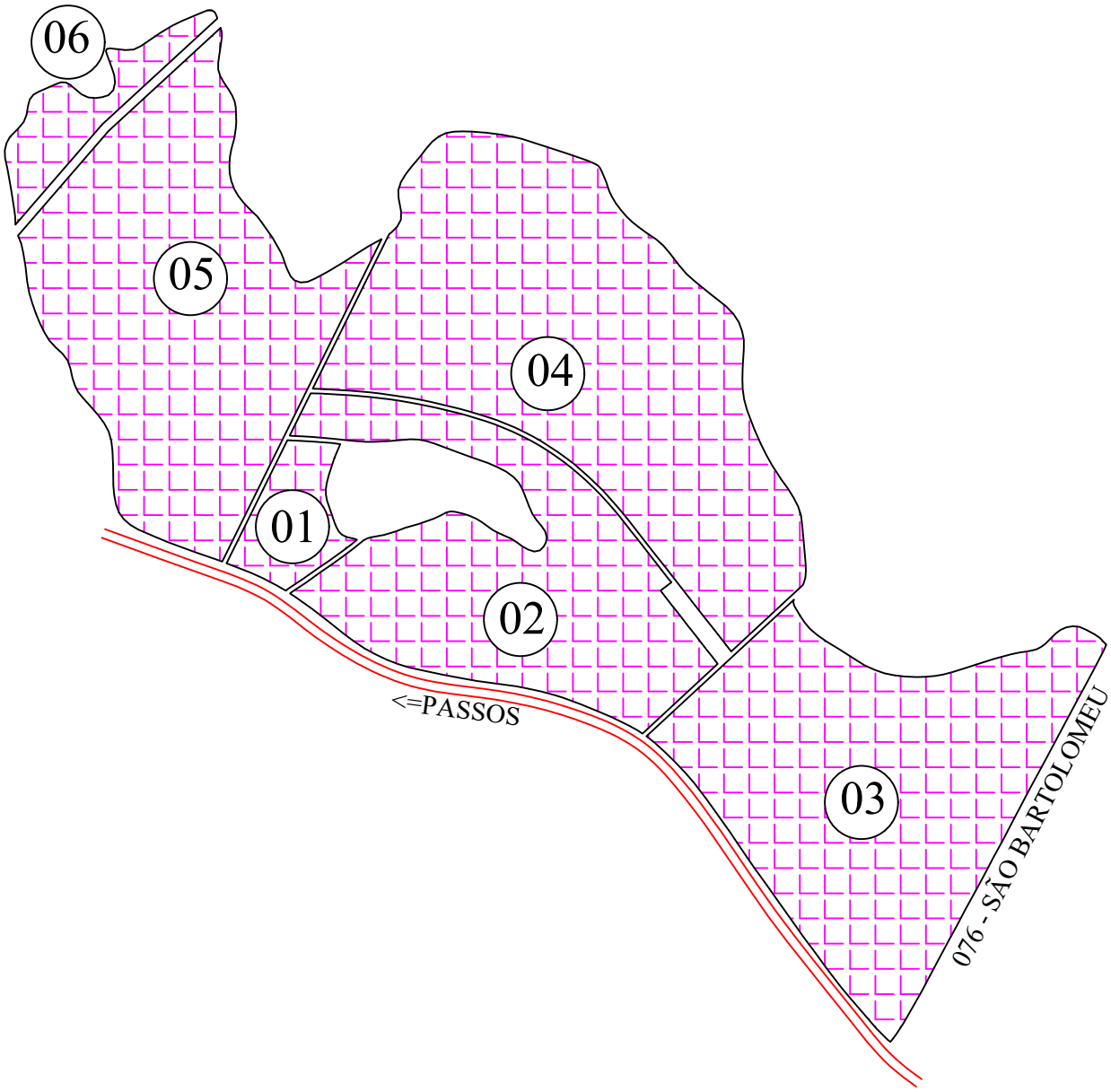

RB 96-6928

TABELA DE VARIEDADE	
VARIEDADE	ÁREA
RB966928	47,59
Total Geral	**47,59**

IPIRANGA AGROINDUSTRIAL

PROJETO: CADERNO DE MAPA 26'27	DATA: 04/03/2026	ESCALA: 1:5000	TOPÓGRAFO: CRISTIAN
FAZENDA: 073 - NINFAS	MUNICÍPIO: PASSOS - MG		ÁREA (ha): 47,59
PROPRIETÁRIO:	UNIDADE: IPIRANGA PASSOS - MG		CÓDIGO: 073

Caderno de Mapas

Bloco	Talhao	Variedade	Estágio de Corte	Amb. Prod.	Data Plantio	Último Corte	Área (ha)	Estimativas Área (ha)	Finalid	Produt.	Prod. Total	Dist.	Esp.	Tipo Corte	Experimento
1 · REG 1			**73 · NINFAS**				**IPIRANGA AGROINDUSTRIAL S.A**								
1	1	RB966928	4C	A	24/12/21	18/07/25	1,27	1,27	1-MO.	75,0	95,25	20	1,5	MEC.	
1	2	RB966928	4C	A	26/12/21	18/07/25	8,24	8,24	1-MO.	75,0	618,00	20	1,5	MEC.	
1	3	RB966928	4C	BA	27/12/21	18/07/25	11,49	11,49	1-MO.	75,0	861,75	20	1,5	MEC.	
1	4	RB966928	4C	A	27/12/21	18/07/25	14,16	14,16	1-MO.	75,0	1.062,00	20	1,5	MEC.	
1	5	RB966928	4C	A	26/12/21	18/07/25	11,08	11,08	1-MO.	75,0	831,00	20	1,5	MEC.	
1	6	RB966928	4C	A	26/12/21	18/07/25	1,35	1,35	1-MO.	75,0	101,25	20	1,5	MEC.	
Total/Média (1 / 73 · NINFAS)							47,59	47,59		75,0	3.569,25				

N: 7703925.213
E: 341382.9768
LAT: −20°45'29.0000" (−20.75805555)
LONG: −46°31'26.4408" (−46.52401134)

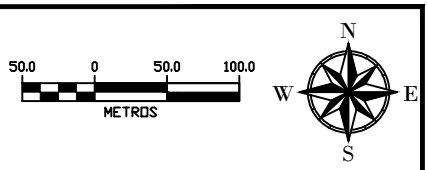

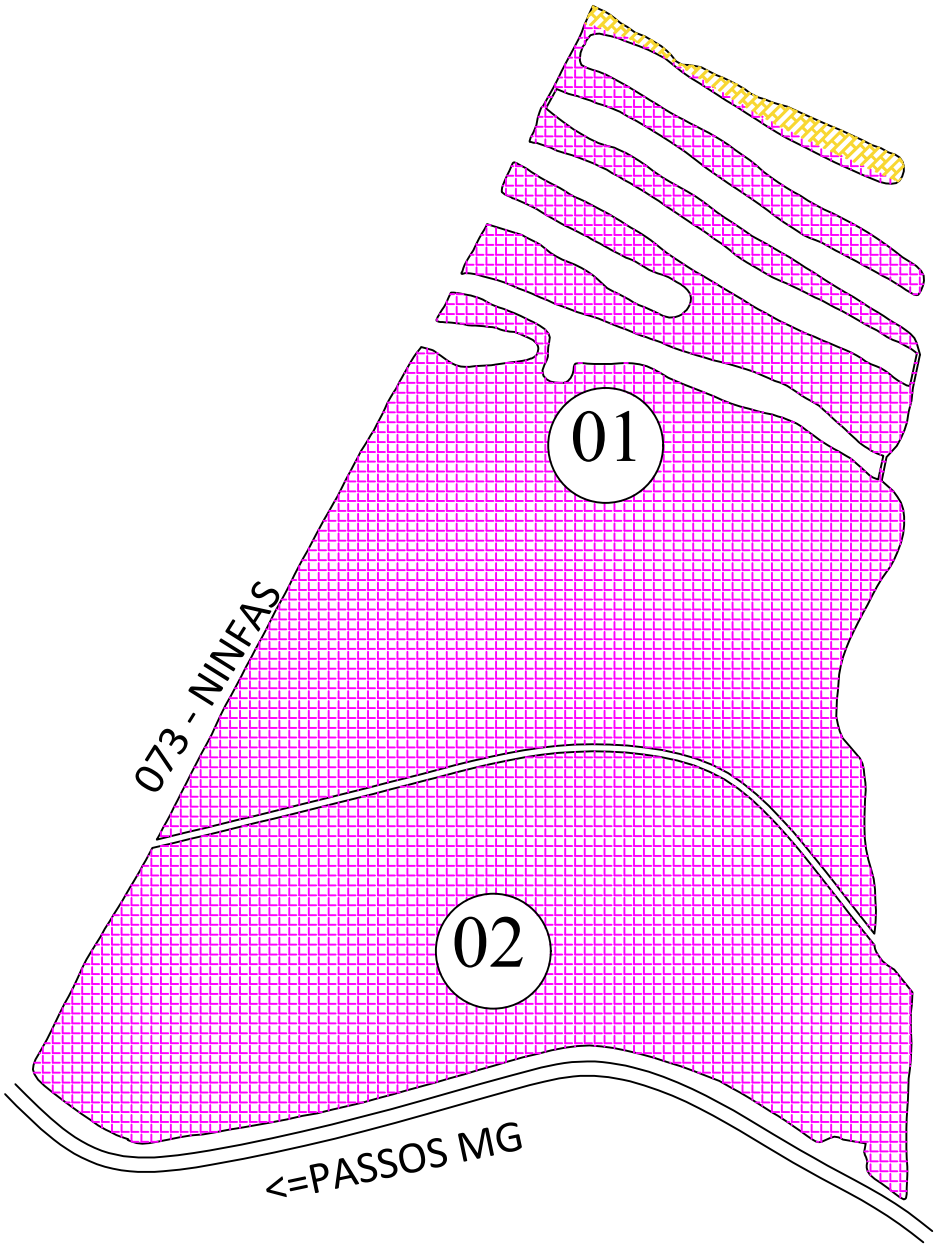

RB 97-5952
RB 96-6928

TABELA DE VARIEDADE	
VARIEDADE	ÁREA
RB966928	25,86
RB975952	0,26
Total Geral	**26,12**

IPIRANGA AGROINDUSTRIAL

PROJETO: CADERNO DE MAPA 26'27	DATA: 04/03/2026	ESCALA: 1:5000	TOPÓGRAFO: CRISTIAN
FAZENDA: 076 - SÃO BARTOLOMEU	MUNICÍPIO: PASSOS - MG		ÁREA (ha): 26,12
PROPRIETÁRIO:	UNIDADE: IPIRANGA PASSOS - MG		CÓDIGO: 076

Caderno de Mapas

Bloco	Talhao	Variedade	Estágio de Corte	Amb. Prod.	Data Plantio	Último Corte	Área (ha)	Estimativas Área (ha)	Finalid	Produt.	Prod. Total	Dist.	Esp.	Tipo Corte	Experimento
1 · REG 1			**76 · S.BARTOL/NINFAS**				**IPIRANGA AGROINDUSTRIAL S.A**								
1	1	RB966928	5C	BA	28/01/21	18/07/25	14,17	14,17	1-MO.	65,0	921,05	20,6	1,5	MEC.	
1	1	RB975952	5C	BA	28/01/21	18/07/25	0,26	0,26	1-MO.	65,0	16,90	20,6	1,5	MEC.	
1	2	RB966928	5C	BA	28/01/21	18/07/25	11,69	11,69	1-MO.	65,0	759,85	20,6	1,5	MEC.	
Total/Média (1 / 76 · S.BARTOL/NINFAS)							26,12	26,12		65,0	1.697,80				

N: 7728460.142
E: 319170.7391
LAT: −20°32'3.9678" (−20.53443550)
LONG: −46°44'5.2471" (−46.73479085)

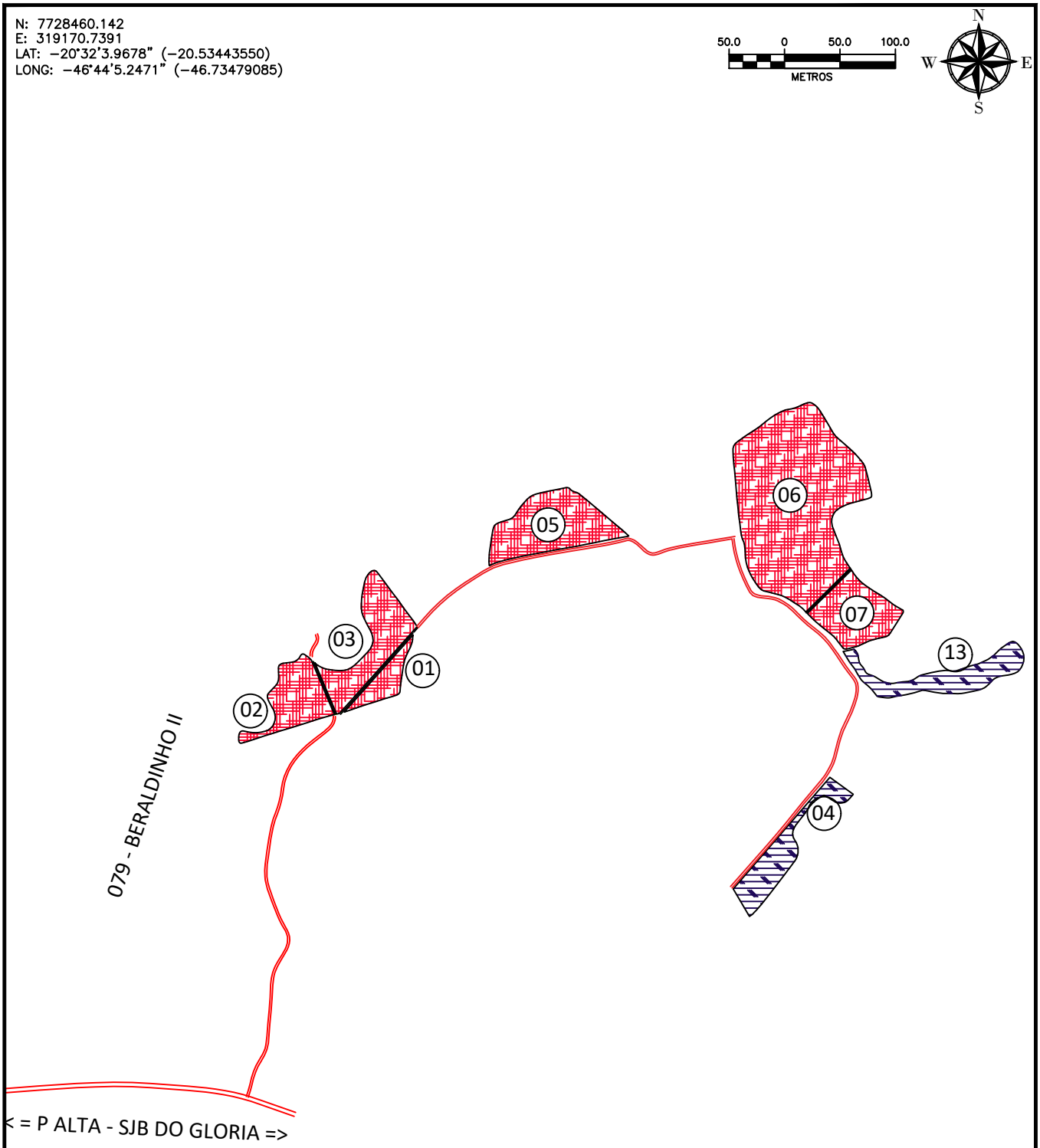

CV-7870

IAC SP 01-5503

TABELA DE VARIEDADE	
VARIEDADE	ÁREA
CV7870	3,84
IACSP01-5503	21,99
Total Geral	**25,83**

IPIRANGA AGROINDUSTRIAL

PROJETO: CADERNO DE MAPA 26'27	DATA: 04/03/2026	ESCALA: 1:5000	TOPÓGRAFO: CRISTIAN
FAZENDA: 094 - RANCHÃO V	MUNICÍPIO: PASSOS MG		ÁREA (ha): 25,83
PROPRIETÁRIO:	UNIDADE: IPIRANGA PASSOS		CÓDIGO: 094

Caderno de Mapas

Bloco	Talhao	Variedade	Estágio de Corte	Amb. Prod.	Data Plantio	Data Último Corte	Área (ha)	Estimativas Área (ha)	Estimativas Finalid	Estimativas Produt.	Prod. Total	Dist.	Esp.	Tipo Corte	Experimento
1 · REG 1			**94 · RANCHAO V**				**IPIRANGA AGROINDUSTRIAL S.A**								
1	1	IACSP01-5503	3C	BA	07/11/23	05/08/25	0,82	0,82	1-MO.	78,0	63,96	26	1,5	MEC.	
1	2	IACSP01-5503	3C	BA	07/11/23	05/08/25	1,96	1,96	1-MO.	78,0	152,88	26	1,5	MEC.	
1	3	IACSP01-5503	3C	BA	07/11/23	05/08/25	2,65	2,65	1-MO.	78,0	206,70	26	1,5	MEC.	
1	4	CV7870	3C	B	24/03/23	05/08/25	1,80	1,80	1-MO.	78,0	140,40	26	1,5	MEC.	
1	5	IACSP01-5503	3C	B	07/11/23	05/08/25	3,39	3,39	1-MO.	78,0	264,42	26	1,5	MEC.	
1	6	IACSP01-5503	3C	B	05/10/23	05/08/25	10,83	10,83	1-MO.	78,0	844,74	26	1,5	MEC.	
1	7	IACSP01-5503	3C	B	04/11/23	05/08/25	2,34	2,34	1-MO.	78,0	182,52	26	1,5	MEC.	
1	13	CV7870	3C	B	24/03/23	05/08/25	2,04	2,04	1-MO.	78,0	159,12	26	1,5	MEC.	
Total/Média (1 / 94 · RANCHAO V)							25,83	25,83		78,0	2.014,74				

N: 7721262.764
E: 328226.9782
LAT: −20°36'1.0510" (−20.60029196)
LONG: −46°38'55.1549" (−46.64865413)

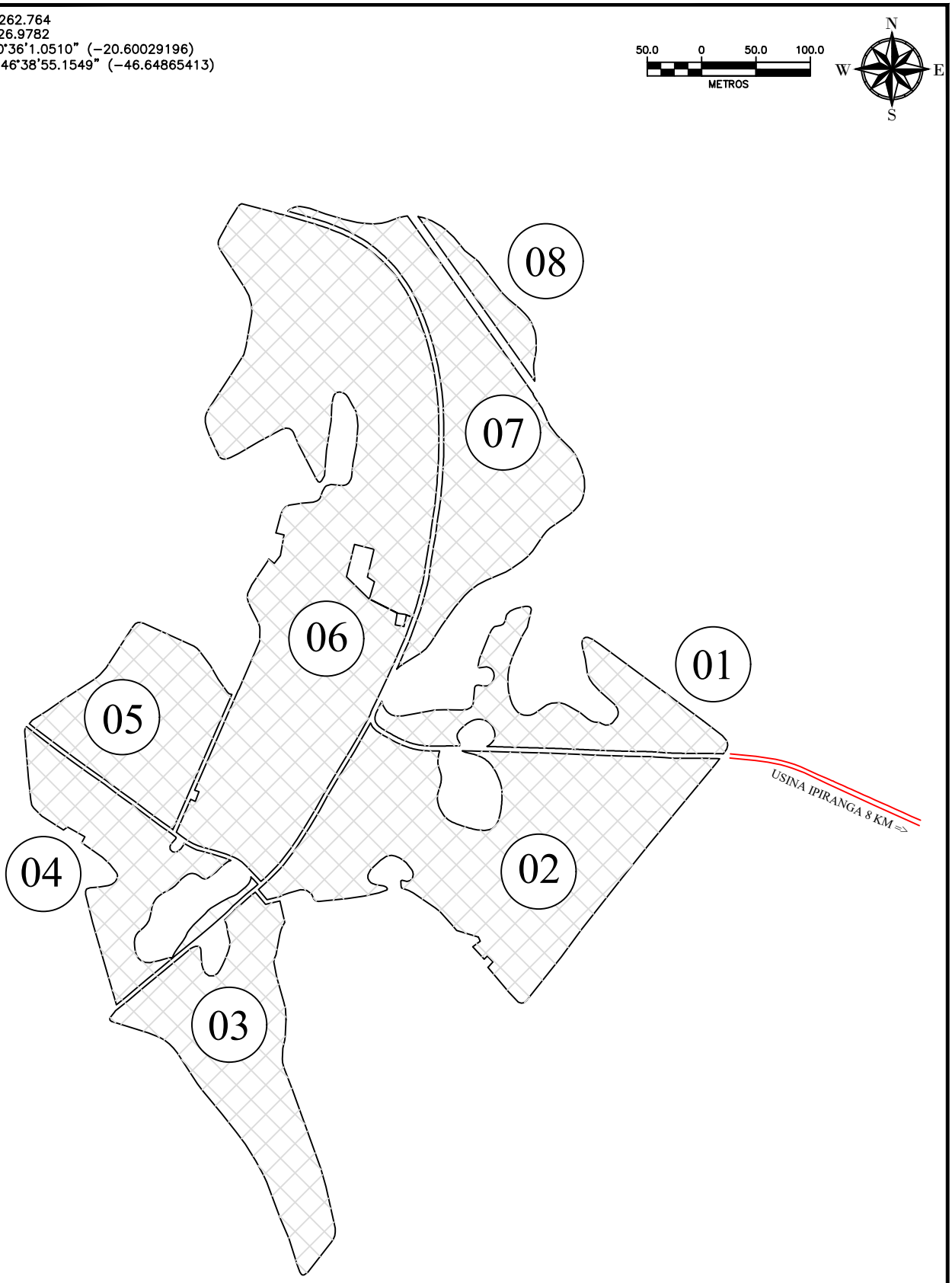

CTC - 4

TABELA DE VARIEDADE	
VARIEDADE	ÁREA
CTC4	40,15
Total Geral	**40,15**

IPIRANGA AGROINDUSTRIAL

PROJETO: CADERNO DE MAPA 26'27	DATA: 05/03/2026	ESCALA: 1:5000	TOPÓGRAFO: CRISTIAN
FAZENDA: 102 - SANTO ANTONIO	MUNICÍPIO: PASSOS MG		ÁREA (ha): 40,15
PROPRIETÁRIO: PAULO FRANK	UNIDADE: IPRANGA PASSOS		CÓDIGO: 102

Caderno de Mapas

Bloco	Talhao	Variedade	Estágio de Corte	Amb. Prod.	Data Plantio	Último Corte	Área (ha)	Estimativas Área (ha)	Finalid	Produt.	Prod. Total	Dist.	Esp.	Tipo Corte	Experimento
1 · REG 1			**102 · STO ANTONIO II**				**IPIRANGA AGROINDUSTRIAL S.A**								
1	1	CTC4	3C	A	26/04/23	31/10/25	2,56	2,56	1-MO.	85,0	217,60	17,3	1,5	MEC.	
1	2	CTC4	3C	A	29/04/23	31/10/25	8,07	8,07	1-MO.	85,0	685,95	17,3	1,5	MEC.	
1	3	CTC4	3C	A	02/05/23	31/10/25	4,30	4,30	1-MO.	85,0	365,50	17,3	1,5	MEC.	
1	4	CTC4	3C	A	01/05/23	18/02/25	2,65	2,65	1-MO.	85,0	225,25	17,3	1,5	MEC.	
1	5	CTC4	3C	A	29/04/23	18/02/25	3,12	3,12	1-MO.	85,0	265,20	17,3	1,5	MEC.	
1	6	CTC4	3C	A	28/04/23	31/10/25	13,80	13,80	1-MO.	85,0	1.173,00	17,3	1,5	MEC.	
1	7	CTC4	3C	A	26/04/23	31/10/25	5,06	5,06	1-MO.	85,0	430,10	17,3	1,5	MEC.	
1	8	CTC4	3C	A	26/04/23	31/10/25	0,59	0,59	1-MO.	85,0	50,15	17,3	1,5	MEC.	
Total/Média (1 / 102 · STO ANTONIO II)							40,15	40,15		85,0	3.412,75				

N: 7728314.853
E: 317674.5167
LAT: −20°32'8.1729" (−20.53560358)
LONG: −46°44'56.9460" (−46.74915168)

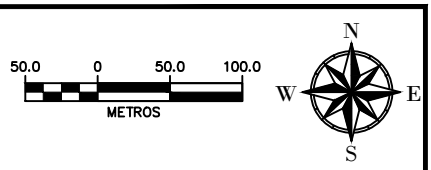

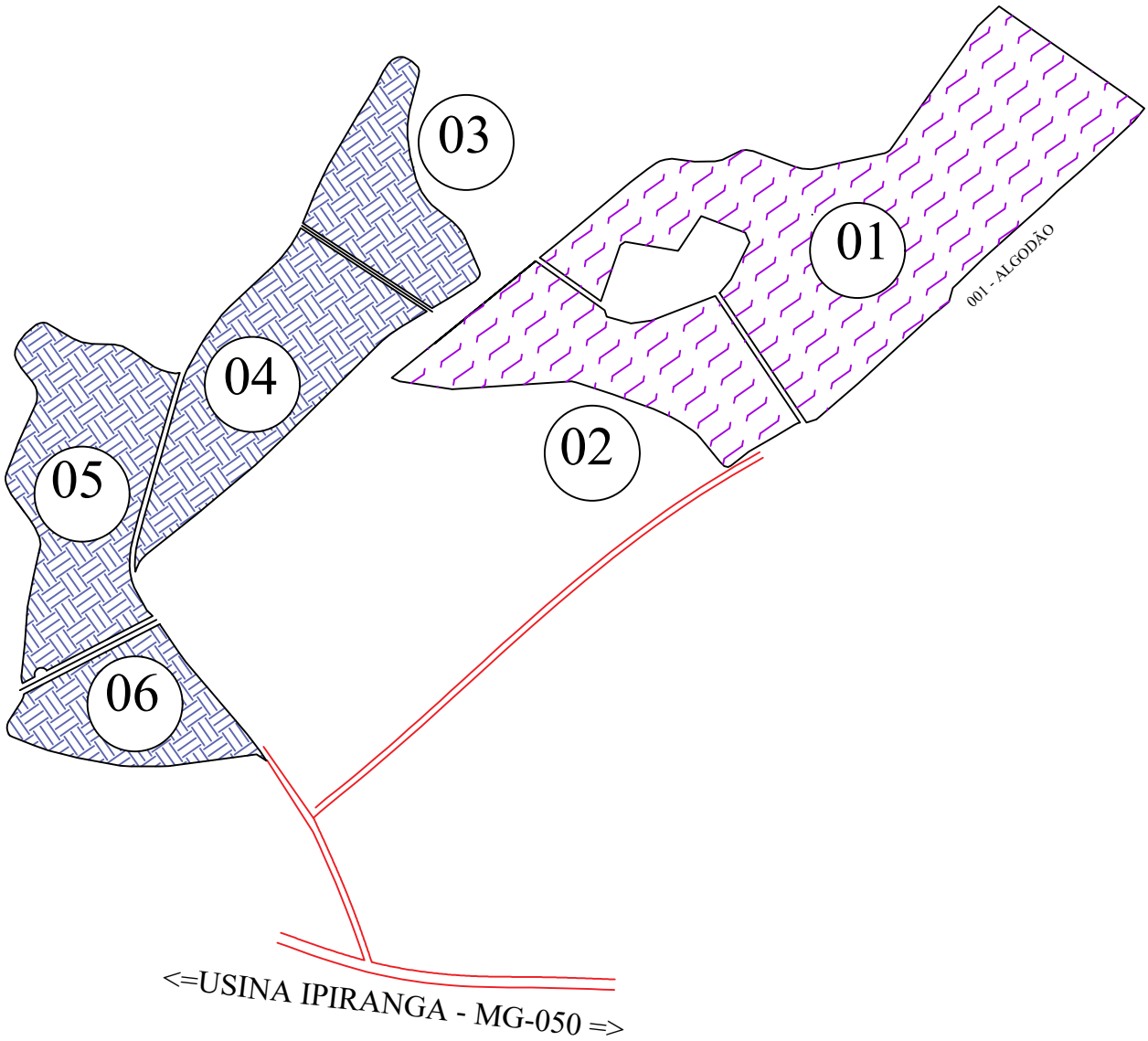

CTC - 9003
CTC - 9007

TABELA DE VARIEDADE	
VARIEDADE	ÁREA
CTC9003	10,38
CTC9007	11,10
Total Geral	**21,48**

IPIRANGA AGROINDUSTRIAL

PROJETO: CADERNO DE MAPA 26'27	DATA: 05/03/2026	ESCALA: 1:5000	TOPÓGRAFO: CRISTIAN
FAZENDA: 103 - SOLEDADE IV	MUNICÍPIO: PASSOS MG		ÁREA (ha): 21,48
PROPRIETÁRIO: ÂNGELO GIOVANNI DE OLIVEIRA	UNIDADE: IPIRANGA PASSOS		CÓDIGO: 103

Caderno de Mapas

Bloco	Talhao	Variedade	Estágio de Corte	Amb. Prod.	Data Plantio	Data Último Corte	Área (ha)	Estimativas Área (ha)	Estimativas Finalid	Estimativas Produt.	Prod. Total	Dist.	Esp.	Tipo Corte	Experimento
1 · REG 1			**103 · SOLEDADE IV**				**IPIRANGA AGROINDUSTRIAL S.A**								
1	1	CTC9007	3C	BA	05/04/23	12/09/25	7,97	7,97	1-MO.	90,0	717,30	6,6	1,5	MEC.	
1	2	CTC9007	3C	A	06/04/23	12/09/25	3,13	3,13	1-MO.	90,0	281,70	6,6	1,5	MEC.	
1	3	CTC9003	3C	A	27/05/23	12/09/25	1,82	1,82	1-MO.	85,0	154,70	6,6	1,5	MEC.	
1	4	CTC9003	3C	A	26/05/23	12/09/25	3,24	3,24	1-MO.	85,0	275,40	6,6	1,5	MEC.	
1	5	CTC9003	3C	A	26/05/23	12/09/25	3,44	3,44	1-MO.	85,0	292,40	6,6	1,5	MEC.	
1	6	CTC9003	3C	A	26/05/23	12/09/25	1,88	1,88	1-MO.	85,0	159,80	6,6	1,5	MEC.	
Total/Média (1 / 103 · SOLEDADE IV)							21,48	21,48		87,6	1.881,30				

N: 7713853.634
E: 335030.8915
LAT: −20°40'4.1716" (−20.66782545)
LONG: −46°35'2.6806" (−46.58407794)

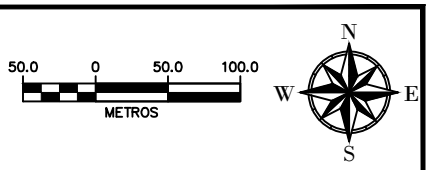

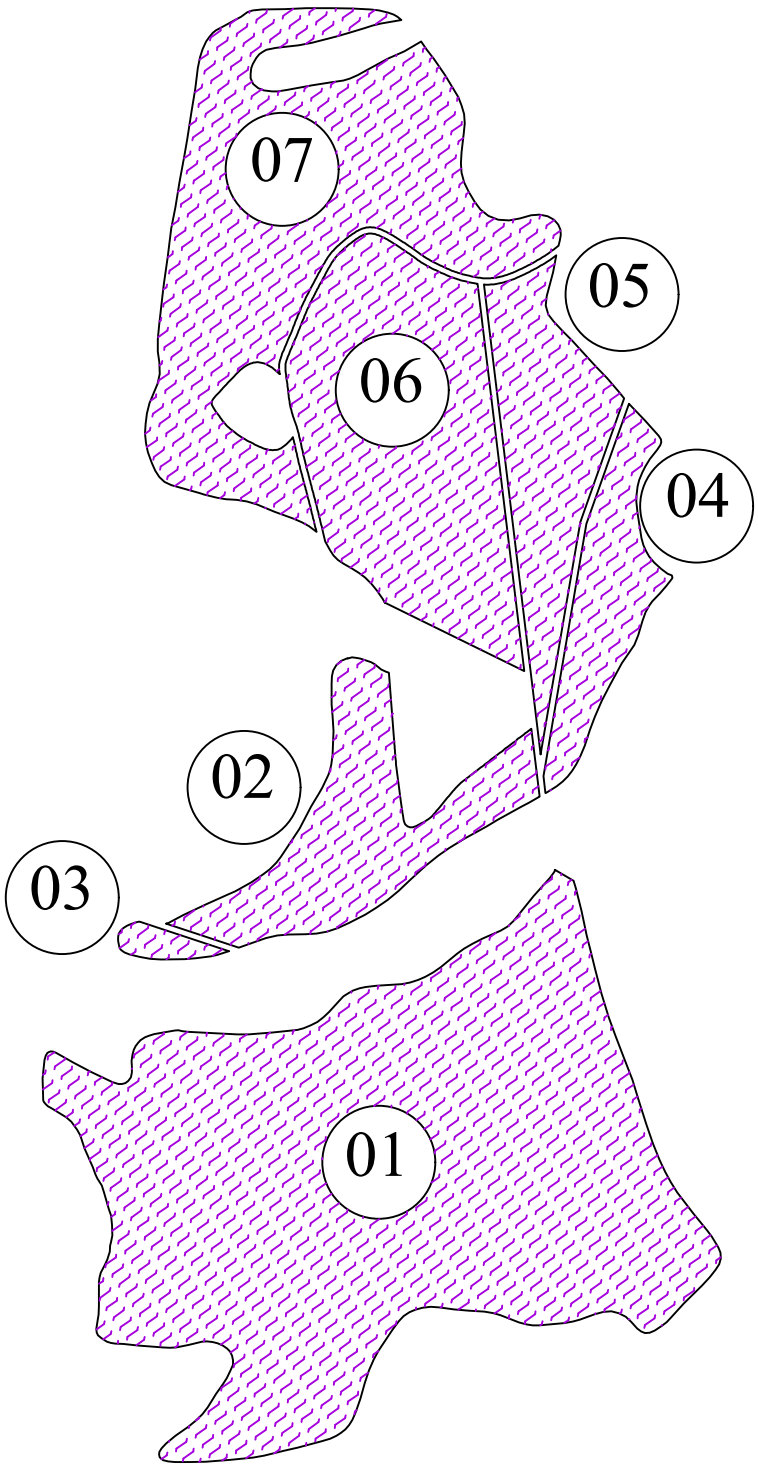

CTC - 9007

TABELA DE VARIEDADE	
VARIEDADE	ÁREA
CTC9007	28,96
Total Geral	**28,96**

IPIRANGA AGROINDUSTRIAL	PROJETO: CADERNO DE MAPA 26'27	DATA: 05/03/2026	ESCALA: 1:5000	TOPÓGRAFO: CRISTIAN
	FAZENDA: 104 - SANTA PAULA	MUNICÍPIO: PASSOS MG		ÁREA (ha): 28,96
	PROPRIETÁRIO: IPIRANGA AGROINDUSTRIAL	UNIDADE: IPIRANGA PASSOS		CÓDIGO: 104

Caderno de Mapas

Bloco	Talhao	Variedade	Estágio de Corte	Amb. Prod.	Data Plantio	Data Último Corte	Área (ha)	Estimativas Área (ha)	Estimativas Finalid	Estimativas Produt.	Prod. Total	Dist.	Esp.	Tipo Corte	Experimento
1 · REG 1			**104 · SANTA PAULA**				**IPIRANGA AGROINDUSTRIAL S.A**								
1	1	CTC9007	3C	CB	18/04/23	18/05/26	13,41	13,41	2-MU.	75,0	1.005,75	37	1,5	MEC.	
1	2	CTC9007	3C	CB	18/04/23	18/05/26	2,22	2,22	2-MU.	75,0	166,50	37	1,5	MEC.	
1	3	CTC9007	3C	CB	18/04/23	18/05/26	0,15	0,15	2-MU.	75,0	11,25	37	1,5	MEC.	
1	4	CTC9007	3C	CB	18/04/23	18/05/26	1,23	1,23	2-MU.	75,0	92,25	37	1,5	MEC.	
1	5	CTC9007	3C	CB	18/04/23	18/05/26	1,91	1,91	2-MU.	75,0	143,25	37	1,5	MEC.	
1	6	CTC9007	3C	CB	18/04/23	18/05/26	4,26	4,26	2-MU.	75,0	319,50	37	1,5	MEC.	
1	7	CTC9007	3C	CB	18/04/23	18/05/26	5,78	5,78	2-MU.	75,0	433,50	37	1,5	MEC.	
Total/Média (1 / 104 · SANTA PAULA)							28,96	28,96		75,0	2.172,00				

N: 7713853.634
E: 335030.8915
LAT: −20°40'4.1716" (−20.66782545)
LONG: −46°35'2.6806" (−46.58407794)

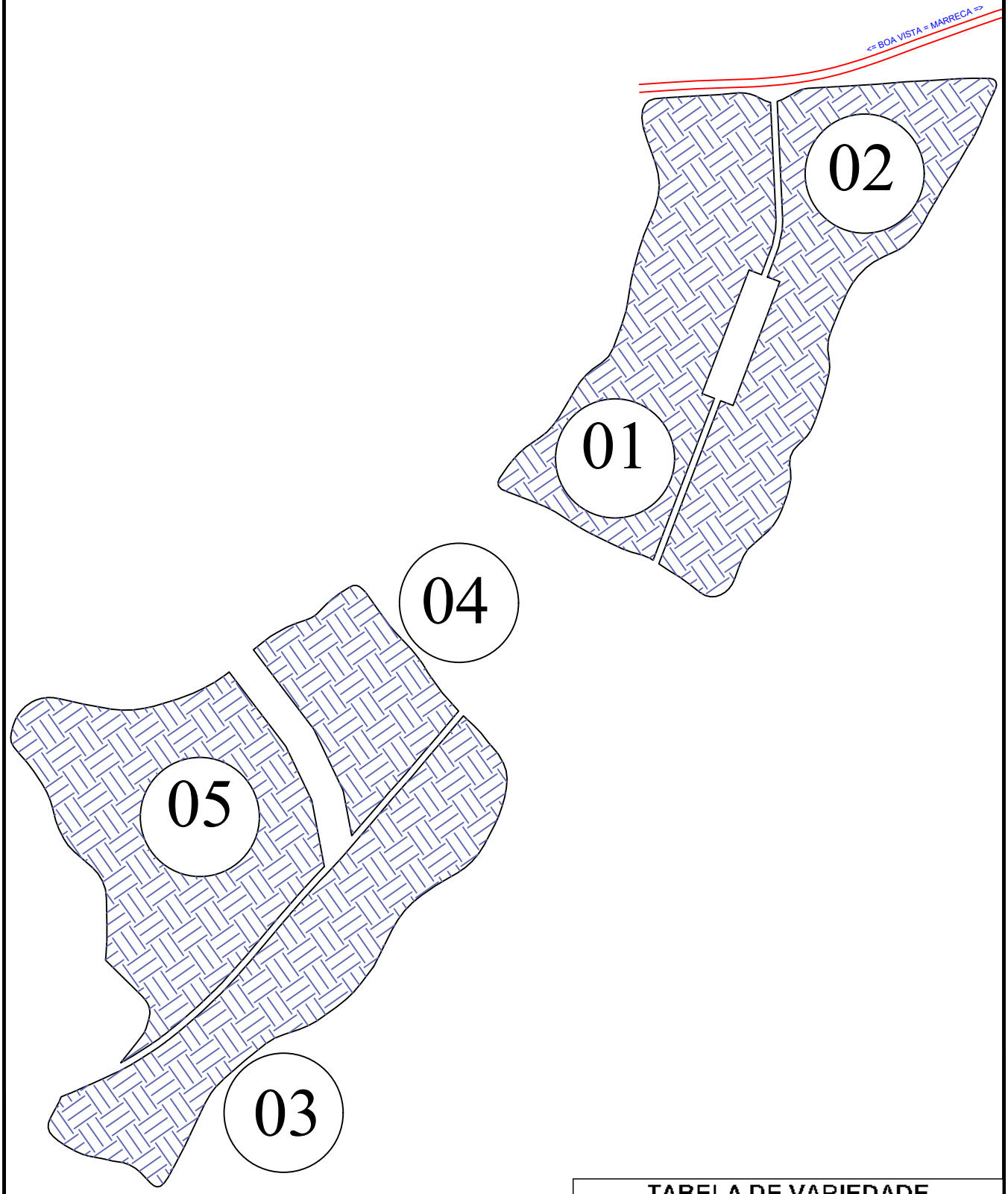

CTC - 9003

TABELA DE VARIEDADE	
VARIEDADE	ÁREA
CTC9003	14,60
Total Geral	**14,60**

IPIRANGA AGROINDUSTRIAL	PROJETO: CADERNO DE MAPA 25'26	DATA: 28-04-2025 / ESCALA: 1:5000	TOPÓGRAFO: CRISTIAN
	FAZENDA: 105 - BALSAMO	MUNICÍPIO: PASSOS - MG	ÁREA (ha): 14,60
	PROPRIETÁRIO: LUCAS GIANNELLI RIGHETTO	UNIDADE: IPIRANGA PASSOS S.A.	CÓDIGO: 105

Caderno de Mapas

Bloco	Talhao	Variedade	Estágio de Corte	Amb. Prod.	Data Plantio	Último Corte	Área (ha)	Estimativas Área (ha)	Finalid	Produt.	Prod. Total	Dist.	Esp.	Tipo Corte	Experimento
1 · REG 1			**105 · BALSAMO**				**IPIRANGA AGROINDUSTRIAL S.A**								
1	1	CTC9003	3C	A	28/03/23	02/04/26	3,28	3,28	1-MO.	86,0	282,08	41	1,5	MEC.	
1	2	CTC9003	3C	A	28/03/23	02/04/26	3,33	3,33	1-MO.	86,0	286,38	41	1,5	MEC.	
1	3	CTC9003	3C	A	29/03/23	02/04/26	2,91	2,91	1-MO.	86,0	250,26	41	1,5	MEC.	
1	4	CTC9003	3C	CB	29/03/23	02/04/26	1,36	1,36	1-MO.	86,0	116,96	41	1,5	MEC.	
1	5	CTC9003	3C	CB	29/03/23	02/04/26	3,72	3,72	1-MO.	86,0	319,92	41	1,5	MEC.	
Total/Média (1 / 105 · BALSAMO)							14,60	14,60		86,0	1.255,60				

N: 7713853.634
E: 335030.8915
LAT: −20°40'4.1716" (−20.66782545)
LONG: −46°35'2.6806" (−46.58407794)

50.0 0 50.0 100.0
METROS

N
W E
S

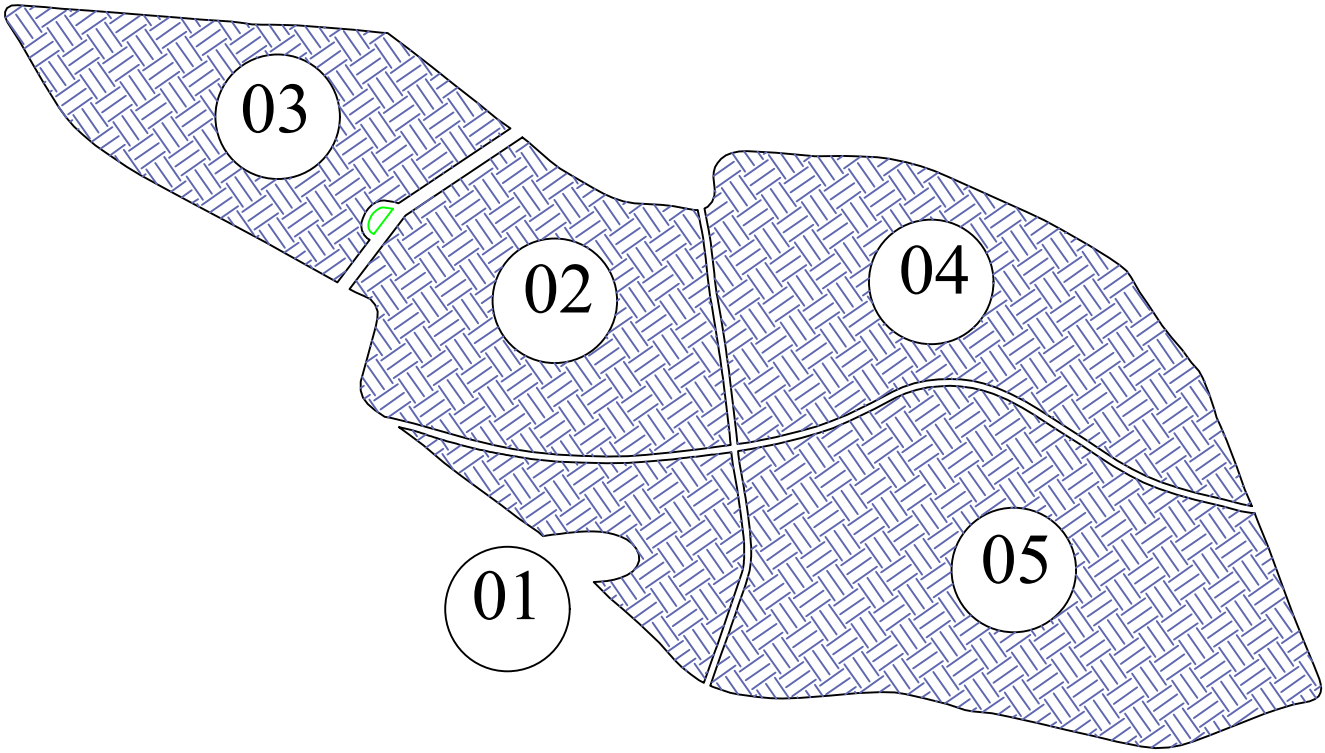

CTC - 9003

TABELA DE VARIEDADE	
VARIEDADE	ÁREA
CTC9003	23,67
Total Geral	**23,67**

IPIRANGA AGROINDUSTRIAL

PROJETO: CADERNO DE MAPA 26'27	DATA: 05/03/2026	ESCALA: 1:5000	TOPÓGRAFO: CRISTIAN
FAZENDA: 106 - LIMEIRA	MUNICÍPIO: PASSOS - MG		ÁREA (ha): 23,67
PROPRIETÁRIO:	UNIDADE: IPIRANGA PASSOS S.A.		

Caderno de Mapas

Bloco	Talhao	Variedade	Estágio de Corte	Amb. Prod.	Data Plantio	Data Último Corte	Área (ha)	Estimativas Área (ha)	Estimativas Finalid	Estimativas Produt.	Prod. Total	Dist.	Esp.	Tipo Corte	Experimento
1 · REG 1			**106 · LIMEIRA**					**IPIRANGA AGROINDUSTRIAL S.A**							
1	1	CTC9003	3C	CB	17/04/23	21/05/26	1,69	1,69	1-MO.	40,0	67,60	41	1,5	MEC.	
1	2	CTC9003	3C	CB	21/04/23	21/05/26	4,59	4,59	1-MO.	75,0	344,25	41	1,5	MEC.	
1	3	CTC9003	3C	CB	22/04/23	21/05/26	3,95	3,95	1-MO.	75,0	296,25	41	1,5	MEC.	
1	4	CTC9003	3C	CB	21/04/23	21/05/26	5,62	5,62	1-MO.	75,0	421,50	41	1,5	MEC.	
1	5	CTC9003	3C	CB	21/04/23	21/05/26	7,82	7,82	1-MO.	40,0	312,80	41	1,5	MEC.	
Total/Média (1 / 106 · LIMEIRA)							23,67	23,67		60,9	1.442,40				

N: 7713853.634
E: 335030.8915
LAT: −20°40'4.1716" (−20.66782545)
LONG: −46°35'2.6806" (−46.58407794)

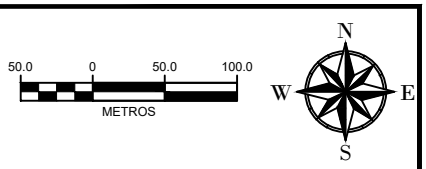

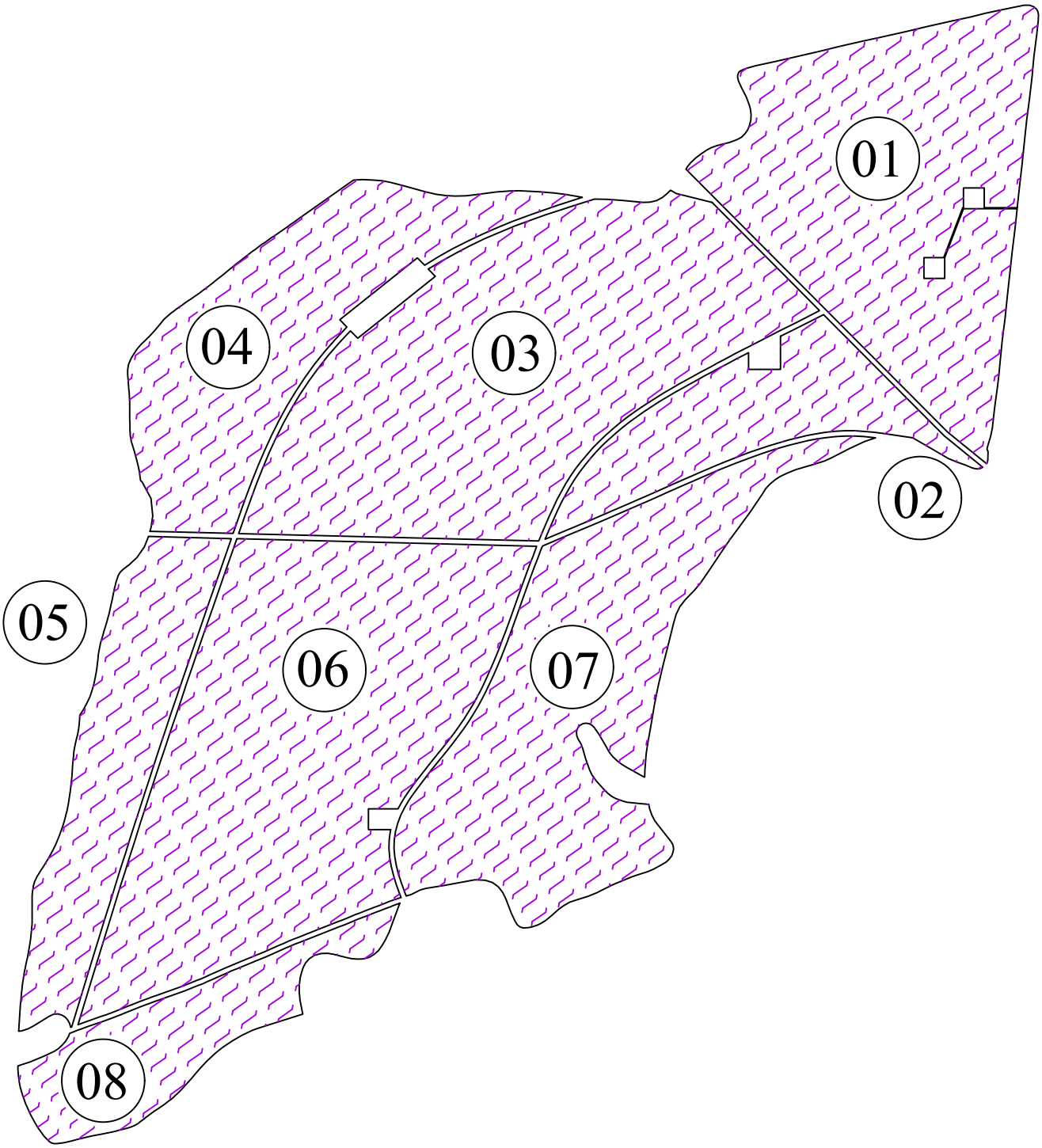

CTC - 9007

TABELA DE VARIEDADE	
VARIEDADE	ÁREA
CTC9007	51,31
Total Geral	**51,31**

IPIRANGA AGROINDUSTRIAL

PROJETO: CADERNO DE MAPA 26'27	DATA: 05/03/2026	ESCALA: 1:5000	TOPÓGRAFO: CRISTIAN
FAZENDA: 107 - PALMITAL	MUNICÍPIO: PASSOS - MG		ÁREA (ha): 51,31
PROPRIETÁRIO:	UNIDADE: IPIRANGA PASSOS S.A.		

Caderno de Mapas

Bloco	Talhao	Variedade	Estágio de Corte	Amb. Prod.	Data Plantio	Último Corte	Área (ha)	Estimativas Área (ha)	Finalid	Produt.	Prod. Total	Dist.	Esp.	Tipo Corte	Experimento
1 · REG 1			**107 · PALMITAL**				**IPIRANGA AGROINDUSTRIAL S.A**								
1	1	CTC9007	3C	A	10/04/23	25/03/26	8,26	8,26	1-MO.	82,0	677,32	50,6	1,5	MEC.	
1	2	CTC9007	3C	A	10/04/23	25/03/26	2,84	2,84	1-MO.	82,0	232,88	50,6	1,5	MEC.	
1	3	CTC9007	3C	A	10/04/23	25/03/26	10,43	10,43	1-MO.	82,0	855,26	50,6	1,5	MEC.	
1	4	CTC9007	3C	A	10/04/23	25/03/26	5,21	5,21	1-MO.	82,0	427,22	50,6	1,5	MEC.	
1	5	CTC9007	3C	B	10/04/23	25/03/26	3,61	3,61	1-MO.	82,0	296,02	50,6	1,5	MEC.	
1	6	CTC9007	3C	B	10/04/23	25/03/26	10,98	10,98	1-MO.	82,0	900,36	50,6	1,5	MEC.	
1	7	CTC9007	3C	B	10/04/23	25/03/26	7,40	7,40	1-MO.	82,0	606,80	50,6	1,5	MEC.	
1	8	CTC9007	3C	B	10/04/23	25/03/26	2,58	2,58	1-MO.	60,0	154,80	50,6	1,5	MEC.	
Total/Média (1 / 107 · PALMITAL)							51,31	51,31		80,9	4.150,66				

N: 7728460.142
E: 319170.7391
LAT: −20°32'3.9678" (−20.53443550)
LONG: −46°44'5.2471" (−46.73479085)

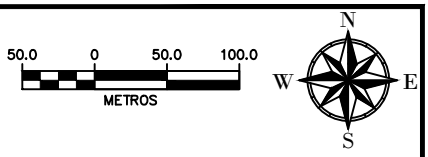

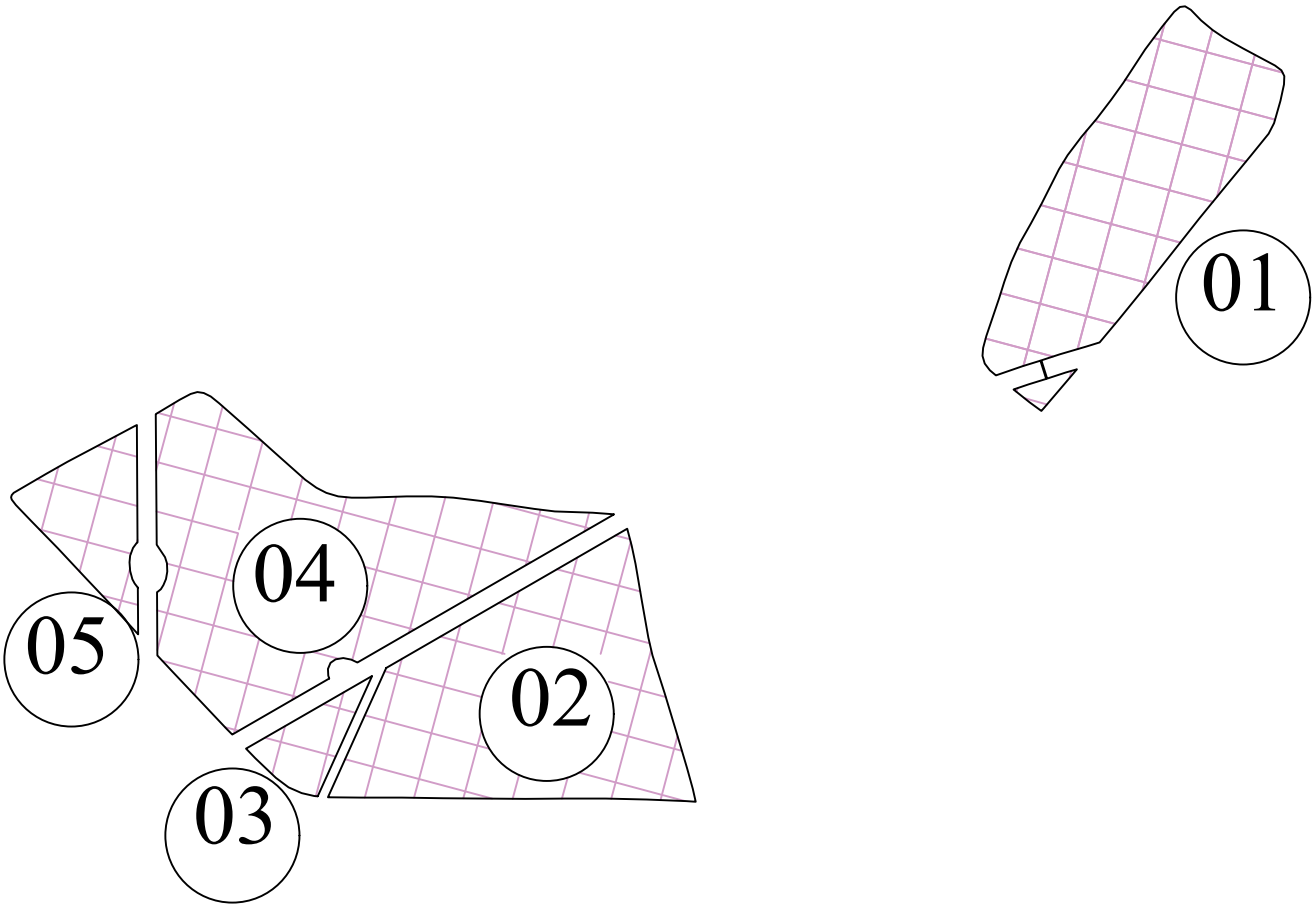

IAC CTC 07-7207

TABELA DE VARIEDADE	
VARIEDADE	ÁREA
IACCTC07-7207	5,54
Total Geral	**5,54**

IPIRANGA AGROINDUSTRIAL

PROJETO: CADERNO DE MAPAS 26'27	DATA: 05/03/2026	ESCALA: 1:5000	TOPÓGRAFO: CRISTIAN
FAZENDA: 108 - LIMEIRA III	MUNICÍPIO: PASSOS MG		ÁREA (ha): 5,54
PROPRIETÁRIO:	UNIDADE: IPIRANGA PASSOS		CÓDIGO: 108

Caderno de Mapas

Bloco	Talhao	Variedade	Estágio de Corte	Amb. Prod.	Data Plantio	Último Corte	Área (ha)	Estimativas Área (ha)	Finalid	Produt.	Prod. Total	Dist.	Esp.	Tipo Corte	Experimento
1 · REG 1			**108 · CRIM/LIM III**				**IPIRANGA AGROINDUSTRIAL S.A**								
1	1	IACCTC07-7207	3C	A	19/12/23	28/07/25	1,40	1,40	1-MO.	80,0	112,00	9,5	1,5	MEC.	
1	2	IACCTC07-7207	2C	A	18/12/23	28/07/25	1,65	1,65	1-MO.	80,0	132,00	9,5	1,5	MEC.	
1	3	IACCTC07-7207	2C	A	19/12/23	28/07/25	0,16	0,16	1-MO.	80,0	12,80	9,5	1,5	MEC.	
1	4	IACCTC07-7207	2C	A	18/12/23	28/07/25	1,97	1,97	1-MO.	80,0	157,60	9,5	1,5	MEC.	
1	5	IACCTC07-7207	2C	A	19/12/23	28/07/25	0,36	0,36	1-MO.	80,0	28,80	9,5	1,5	MEC.	
Total/Média (1 / 108 · CRIM/LIM III)							5,54	5,54		80,0	443,20				

N: 7700983.975
E: 341670.8225
LAT: −20°47'4.7304" (−20.78464734)
LONG: −46°31'17.4474" (−46.52151317)

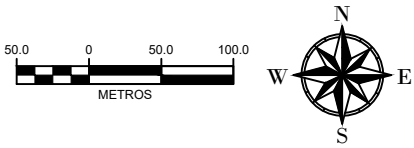

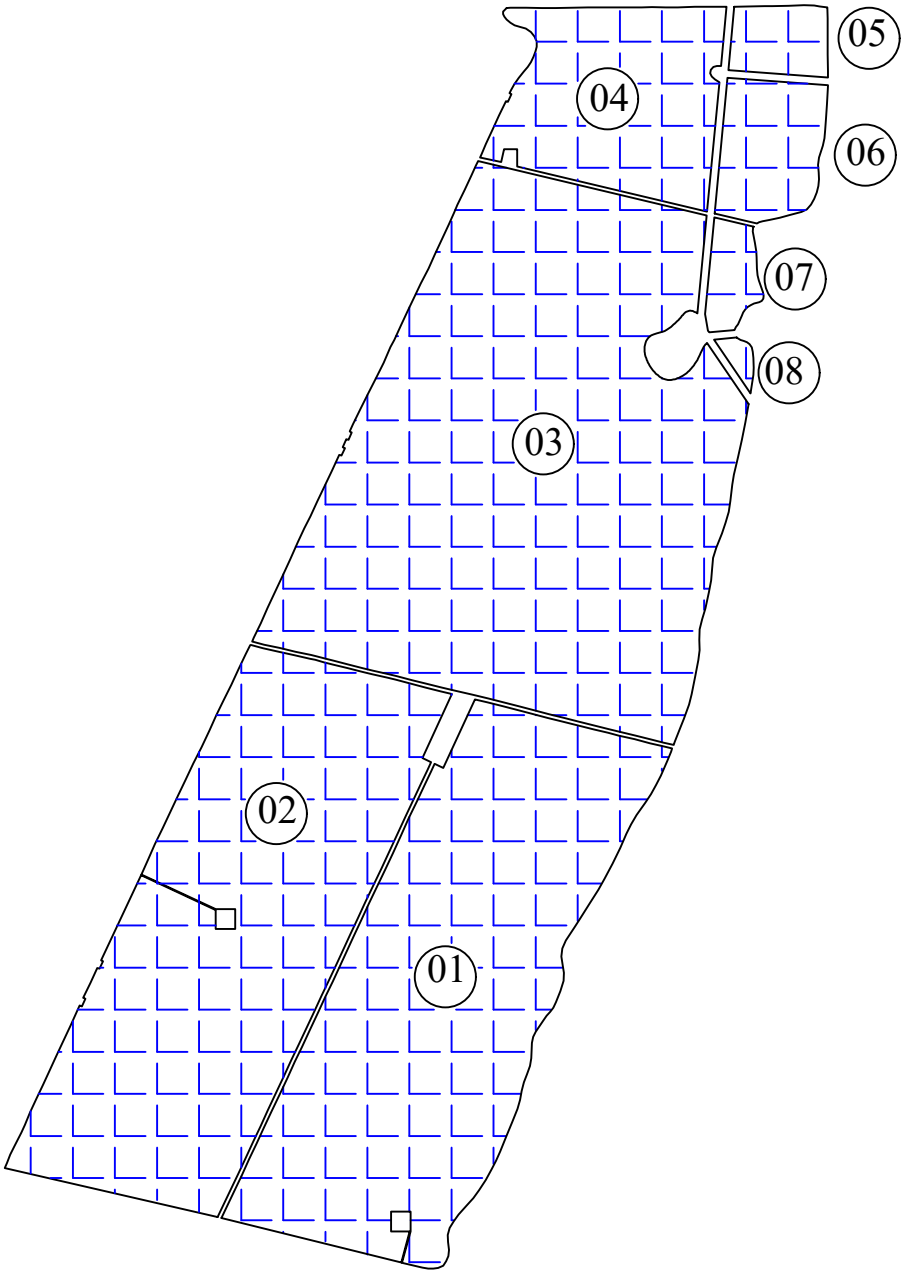

CTC - 2

TABELA DE VARIEDADE	
VARIEDADE	ÁREA
CTC2	83,01
Total Geral	**83,01**

IPIRANGA AGROINDUSTRIAL

PROJETO: CADERNO DE MAPA 26'27	DATA: 05/03/2026	ESCALA: 1:5000	TOPÓGRAFO: CRISTIAN
FAZENDA: 111 - SÍTIO TRES BARRA B	MUNICÍPIO: PASSOS MG		ÁREA (ha): 83,01
PROPRIETÁRIO: FLAVIO VASCONCELOS PEREIRA	UNIDADE: IPIRANGA PASSOS MG		CÓDIGO: 111

Caderno de Mapas

Bloco	Talhao	Variedade	Estágio de Corte	Amb. Prod.	Data Plantio	Último Corte	Área (ha)	Estimativas Área (ha)	Finalid	Produt.	Prod. Total	Dist.	Esp.	Tipo Corte	Experimento
1 · REG 1			**111 · ST 3 BARRAS B**				**IPIRANGA AGROINDUSTRIAL S.A**								
1	1	CTC2	3C	BA	24/04/23	01/07/25	20,35	20,35	1-MO.	90,0	1.831,50	27	1,5	MEC.	
1	2	CTC2	3C	A	23/04/23	01/07/25	20,81	20,81	1-MO.	90,0	1.872,90	27	1,5	MEC.	
1	3	CTC2	3C	BA	26/04/23	01/07/25	31,12	31,12	1-MO.	90,0	2.800,80	27	1,5	MEC.	
1	4	CTC2	3C	BA	27/04/23	01/07/25	6,32	6,32	1-MO.	90,0	568,80	27	1,5	MEC.	
1	5	CTC2	3C	BA	27/04/23	01/07/25	1,10	1,10	1-MO.	90,0	99,00	27	1,5	MEC.	
1	6	CTC2	3C	BA	28/04/23	01/07/25	2,31	2,31	1-MO.	90,0	207,90	27	1,5	MEC.	
1	7	CTC2	3C	BA	28/04/23	01/07/25	0,82	0,82	1-MO.	90,0	73,80	27	1,5	MEC.	
1	8	CTC2	3C	BA	28/04/23	01/07/25	0,18	0,18	1-MO.	90,0	16,20	27	1,5	MEC.	
Total/Média (1 / 111 · ST 3 BARRAS B)							83,01	83,01		90,0	7.470,90				

N: 7713853.634
E: 335030.8915
LAT: −20°40'4.1716" (−20.66782545)
LONG: −46°35'2.6806" (−46.58407794)

50.0 0 50.0 100.0
METROS

N W E S

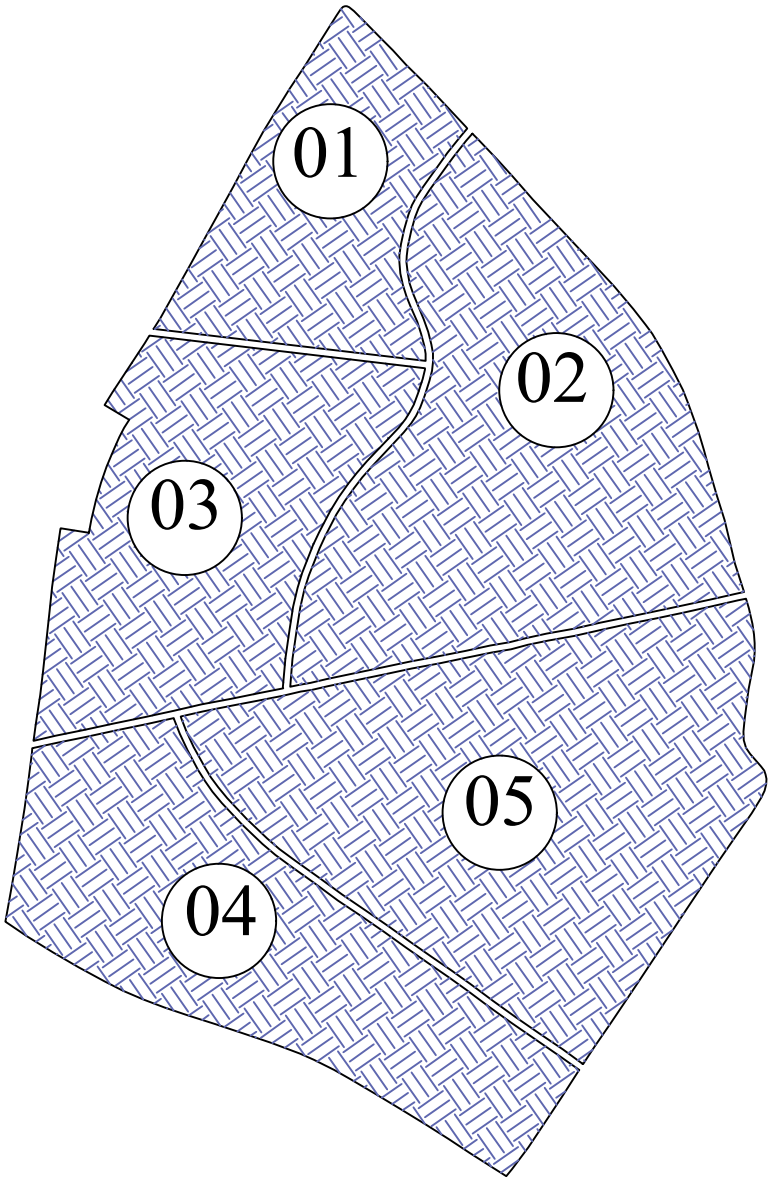

CTC - 9003

TABELA DE VARIEDADE	
VARIEDADE	ÁREA
CTC9003	26,67
Total Geral	**26,67**

IPIRANGA AGROINDUSTRIAL

PROJETO: CADERNO DE MAPA 26'27	DATA: 05/03/2026	ESCALA: 1:5000	TOPÓGRAFO: CRISTIAN
FAZENDA: 112 - BARREIRO	MUNICÍPIO: PASSOS - MG		ÁREA (ha): 26,67
PROPRIETÁRIO: MARIA FERNANDA	UNIDADE: IPIRANGA PASSOS S.A.		

Caderno de Mapas

Bloco	Talhao	Variedade	Estágio de Corte	Amb. Prod.	Data Plantio	Data Último Corte	Área (ha)	Estimativas Área (ha)	Estimativas Finalid	Estimativas Produt.	Prod. Total	Dist.	Esp.	Tipo Corte	Experimento
1 · REG 1			**112 · BARREIRO**				**IPIRANGA AGROINDUSTRIAL S.A**								
1	1	CTC9003	2C	BA	15/12/23	29/04/26	2,89	2,89	1-MO.	75,0	216,75	32	1,5	MEC.	
1	2	CTC9003	2C	BA	15/12/23	29/04/26	6,59	6,59	1-MO.	75,0	494,25	32	1,5	MEC.	
1	3	CTC9003	2C	A	14/12/23	29/04/26	4,58	4,58	1-MO.	75,0	343,50	32	1,5	MEC.	
1	4	CTC9003	2C	BA	14/12/23	29/04/26	5,15	5,15	1-MO.	75,0	386,25	32	1,5	MEC.	
1	5	CTC9003	2C	BA	15/12/23	29/04/26	7,46	7,46	1-MO.	75,0	559,50	32	1,5	MEC.	
Total/Média (1 / 112 · BARREIRO)							26,67	26,67		75,0	2.000,25				

N: 7713853.634
E: 335030.8915
LAT: −20°40'4.1716" (−20.66782545)
LONG: −46°35'2.6806" (−46.58407794)

50.0 0 50.0 100.0
METROS

N
W E
S

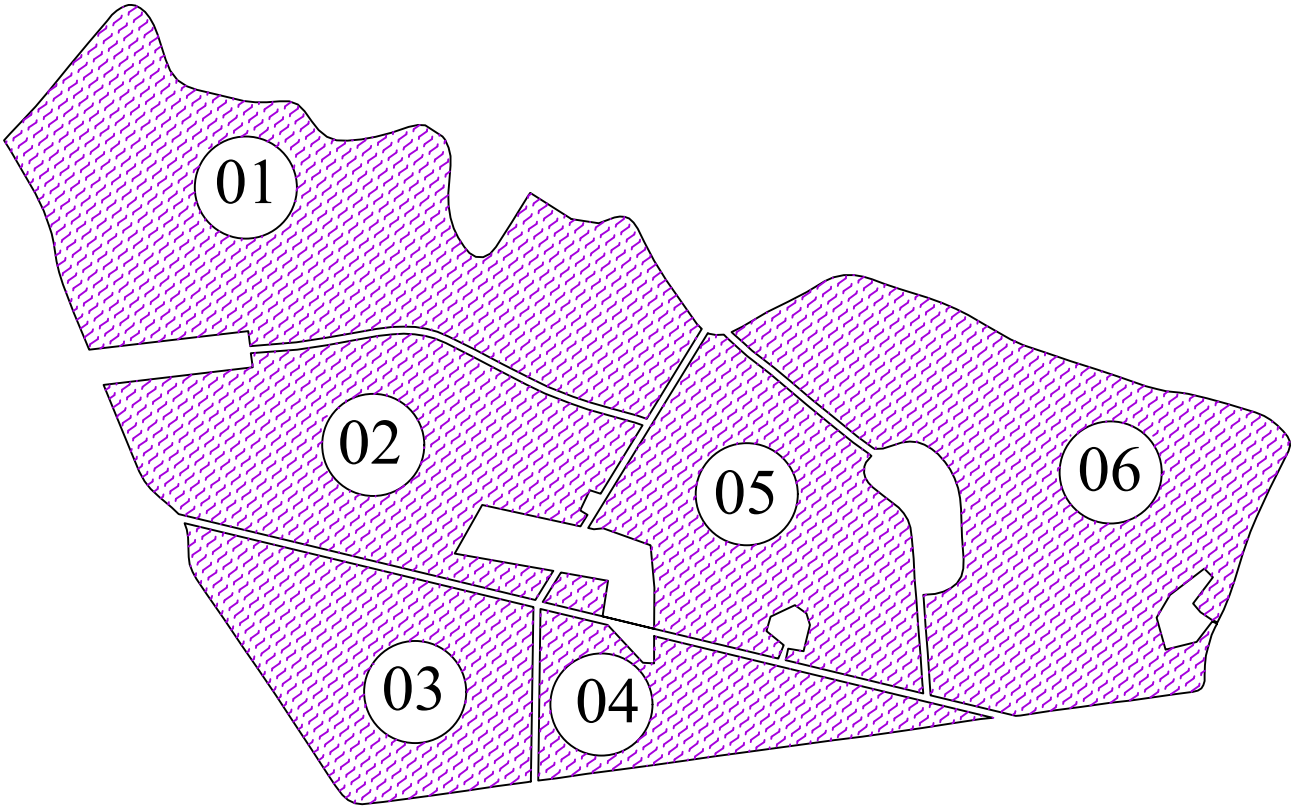

CTC - 9007

TABELA DE VARIEDADE	
VARIEDADE	ÁREA
CTC9007	24,15
Total Geral	**24,15**

IPIRANGA
AGROINDUSTRIAL

PROJETO CADERNO DE MAPA 26'27	DATA 05/03/2026	ESCALA 1:5000	TOPÓGRAFO CRISTIAN
FAZENDA 113 - PONTE GRANDE I	MUNICÍPIO PASSOS - MG		ÁREA (ha) 24,15
PROPRIETÁRIO	UNIDADE IPIRANGA PASSOS S.A.		

Caderno de Mapas

Bloco	Talhao	Variedade	Estágio de Corte	Amb. Prod.	Data Plantio	Último Corte	Área (ha)	Estimativas Área (ha)	Finalid	Produt.	Prod. Total	Dist.	Esp.	Tipo Corte	Experimento
1 · REG 1			**113 · PONTE GRANDE 1**				**IPIRANGA AGROINDUSTRIAL S.A**								
1	1	CTC9007	2C	BA	18/12/23	15/04/25	6,38	6,38	1-MO.	95,0	606,10	36	1,5	MEC.	
1	2	CTC9007	2C	A	18/12/23	15/04/25	3,97	3,97	1-MO.	95,0	377,15	36	1,5	MEC.	
1	3	CTC9007	3C	A	17/12/23	15/04/25	2,88	2,88	1-MO.	95,0	273,60	36	1,5	MEC.	
1	4	CTC9007	3C	A	16/12/23	15/04/25	1,80	1,80	1-MO.	95,0	171,00	36	1,5	MEC.	
1	5	CTC9007	2C	A	16/12/23	15/04/25	3,33	3,33	1-MO.	95,0	316,35	36	1,5	MEC.	
1	6	CTC9007	3C	A	16/12/23	15/04/25	5,79	5,79	1-MO.	95,0	550,05	36	1,5	MEC.	
Total/Média (1 / 113 · PONTE GRANDE 1)							24,15	24,15		95,0	2.294,25				

N: 7728914.37387995
E: 317865.95000925
LAT: −20°31'48.7461819" (−20.53020727276)
LONG: −46°44'50.1168717" (−46.74725468659)

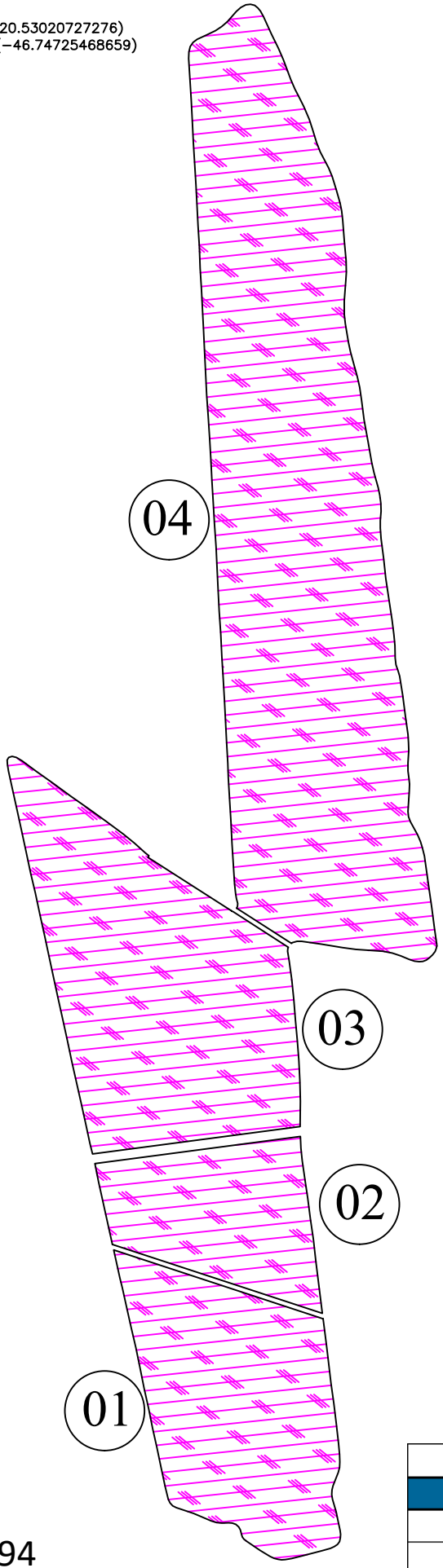

CTC - 2994

TABELA DE VARIEDADE	
VARIEDADE	ÁREA
CTC2994	28,79
Total Geral	**28,79**

IPIRANGA AGROINDUSTRIAL

PROJETO: CADDERNO DE MAPA 26'27	DATA: 05/03/2026	ESCALA: 1:5000	TOPÓGRAFO: CRISTIAN
FAZENDA: 114 - PONTE GRANDE II	MUNICÍPIO: PASSOS - MG		ÁREA (ha): 28,79
PROPRIETÁRIO: TEREZINHA E JAIME	UNIDADE: IPIRANGA PASSOS S.A.		

Caderno de Mapas

Bloco	Talhao	Variedade	Estágio de Corte	Amb. Prod.	Data Plantio	Último Corte	Área (ha)	Estimativas Área (ha)	Finalid	Produt.	Prod. Total	Dist.	Esp.	Tipo Corte	Experimento
1 · REG 1			**114 · PONTE GRANDE 2**				**IPIRANGA AGROINDUSTRIAL S.A**								
1	1	CTC2994	3C	B	24/10/23	14/04/26	4,68	4,68	2-MU.	50,0	234,00	37	1,5	MEC.	
1	2	CTC2994	3C	A	23/10/23	14/04/26	2,66	2,66	2-MU.	50,0	133,00	37	1,5	MEC.	
1	3	CTC2994	3C	A	20/10/23	14/04/26	6,81	6,81	2-MU.	50,0	340,50	37	1,5	MEC.	
1	4	CTC2994	3C	D	21/10/23	24/04/26	14,64	14,64	2-MU.	50,0	732,00	37	1,5	MEC.	
Total/Média (1 / 114 · PONTE GRANDE 2)							28,79	28,79		50,0	1.439,50				

N: 7713853.634
E: 335030.8915
LAT: −20°40'4.1716" (−20.66782545)
LONG: −46°35'2.6806" (−46.58407794)

50.0 0 50.0 100.0
METROS

N
W E
S

CONTROLE

- CADASTRO
- TRANSFERÊNCIA

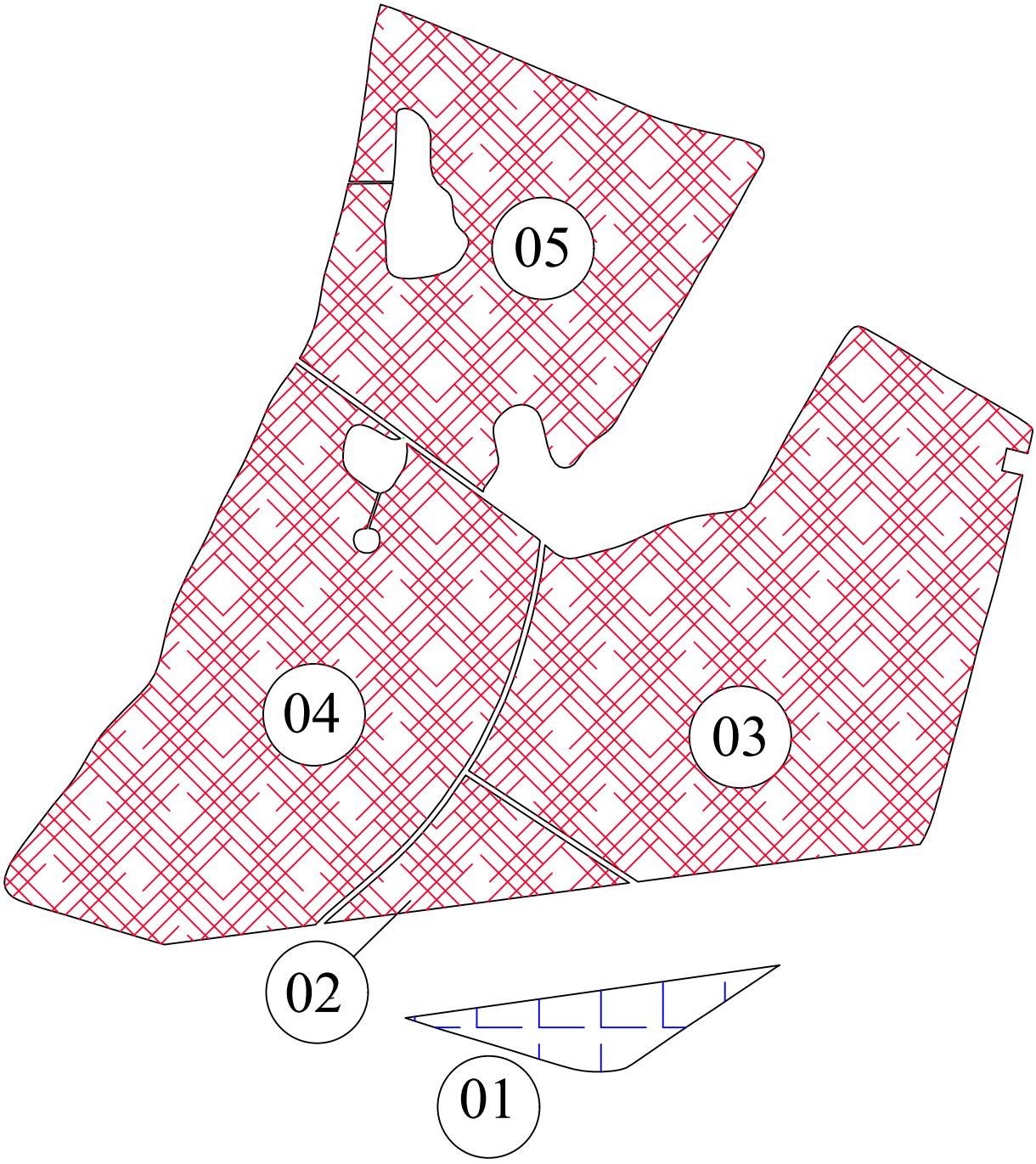

CTC - 2

IAC SP 01-5503

TABELA DE VARIEDADE

VARIEDADE	ÁREA
CTC2	1,00
IACSP01-5503	38,82
Total Geral	**39,82**

IPIRANGA AGROINDUSTRIAL

PROJETO: CADERNO DE MAPA 26'27	DATA: 26/05/2026	ESCALA: 1:5000	TOPÓGRAFO: CRISTIAN
FAZENDA: 115 - VISTA NOBRE	MUNICÍPIO: PASSOS - MG		ÁREA (ha): 39,82
PROPRIETÁRIO:	UNIDADE: IPIRANGA PASSOS S.A.		

Caderno de Mapas

Bloco	Talhao	Variedade	Estágio de Corte	Amb. Prod.	Data Plantio	Data Último Corte	Área (ha)	Estimativas Área (ha)	Estimativas Finalid	Estimativas Produt.	Prod. Total	Dist.	Esp.	Tipo Corte	Experimento
1 · REG 1			**115 · VISTA NOBRE**				**IPIRANGA AGROINDUSTRIAL S.A**								
1	1	CTC2	2C	D	07/11/23	25/03/26	1,00	1,00	1-MO.	100,0	100,00	15	1,5	MEC.	
1	1	IACSP01-5503	2C	D	07/11/23	25/03/26	0,31	0,31	1-MO.	100,0	31,00	15	1,5	MEC.	
1	2	IACSP01-5503	2C	B	07/11/23	25/03/26	1,45	1,45	1-MO.	100,0	145,00	15	1,5	MEC.	
1	3	IACSP01-5503	2C	D	10/11/23	25/03/26	14,46	14,46	1-MO.	100,0	1.446,00	15	1,5	MEC.	
1	4	IACSP01-5503	2C	B	07/11/23	25/03/26	13,03	13,03	1-MO.	100,0	1.303,00	15	1,5	MEC.	
1	5	IACSP01-5503	2C	B	07/11/23	25/03/26	9,57	9,57	1-MO.	100,0	957,00	15	1,5	MEC.	
Total/Média (1 / 115 · VISTA NOBRE)							39,82	39,82		100,0	3.982,00				

N: 7713853.634
E: 335030.8915
LAT: −20°40'4.1716" (−20.66782545)
LONG: −46°35'2.6806" (−46.58407794)

50.0 0 50.0 100.0
METROS

N S W E

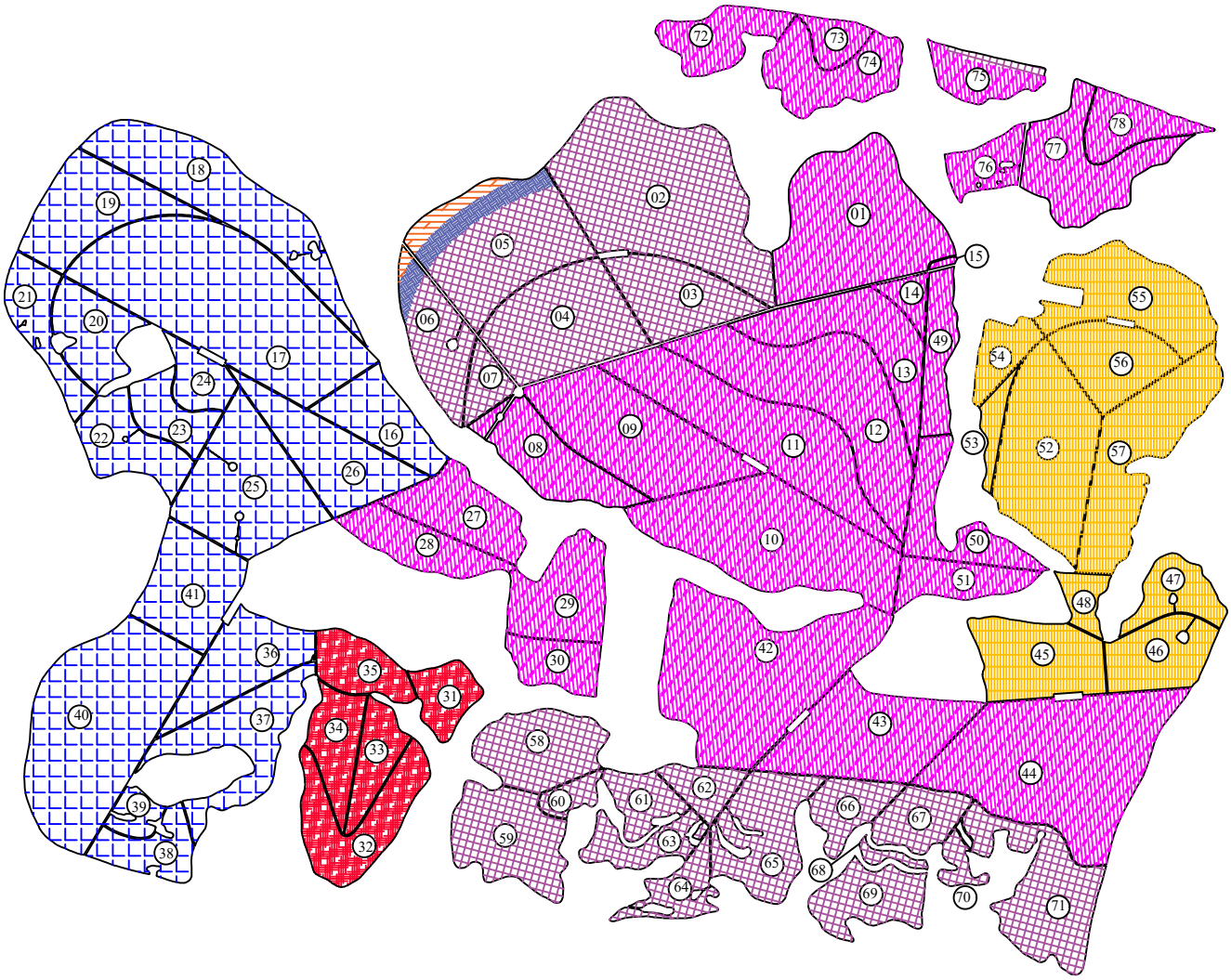

CTC - 2
CTC - 9001
CTC - 9003
CTC -2994
RB 98-5476
IAC SP 01-5503
IAC CTC 07-8008

TABELA DE VARIENDADE

VARIEDADE	ÁREA
CTC2	197,48
CTC2994	298,30
CTC9001BT	2,50
CTC9003BT	4,47
IACCTC07-8008	163,88
IACSP01-5503	30,52
RB985476	88,33
TOTAL	**785,48**

IPIRANGA AGROINDUSTRIAL

PROJETO: CADERNO DE MAPA 26'27	DATA: 05/03/2026	ESCALA: 1:5000	TOPÓGRAFO: CRISTIAN
FAZENDA: 117 - BOM JARDIM	MUNICÍPIO: PASSOS - MG		ÁREA (ha): 785,48
PROPRIETÁRIO: FUAD	UNIDADE: IPIRANGA PASSOS S.A.		

Caderno de Mapas

Bloco	Talhao	Variedade	Estágio de Corte	Amb. Prod.	Data Plantio	Último Corte	Área (ha)	Estimativas Área (ha)	Finalid	Produt.	Prod. Total	Dist.	Esp.	Tipo Corte	Experimento
1 · REG 1			**117 · BOM JARDIM**				**IPIRANGA AGROINDUSTRIAL S.A**								
1	1	CTC2994	2C	BA	30/07/24	24/09/25	23,15	23,15	1-MO.	106,0	2.453,90	62	1,5	MEC.	
1	2	IACCTC07-8008	2C	BA	13/04/24	24/09/25	31,06	31,06	1-MO.	106,0	3.292,36	62	1,5	MEC.	
1	3	IACCTC07-8008	2C	B	14/04/24	24/09/25	9,64	9,64	1-MO.	106,0	1.021,84	62	1,5	MEC.	
1	4	IACCTC07-8008	2C	B	13/04/24	24/09/25	15,62	15,62	1-MO.	106,0	1.655,72	62	1,5	MEC.	
1	5	CTC9001BT	2C	BA	25/03/24	24/09/25	2,20	2,20	1-MO.	106,0	233,20	62	1,5	MEC.	
1	5	CTC9003BT	2C	BA	25/03/24	24/09/25	3,48	3,48	1-MO.	106,0	368,88	62	1,5	MEC.	
1	5	IACCTC07-8008	2C	BA	25/03/24	24/09/25	14,21	14,21	1-MO.	106,0	1.506,26	62	1,5	MEC.	
1	6	CTC9001BT	2C	BA	27/03/24	24/09/25	0,30	0,30	1-MO.	106,0	31,80	62	1,5	MEC.	
1	6	CTC9003BT	2C	BA	27/03/24	24/09/25	0,99	0,99	1-MO.	106,0	104,94	62	1,5	MEC.	
1	6	IACCTC07-8008	2C	BA	27/03/24	24/09/25	7,10	7,10	1-MO.	106,0	752,60	62	1,5	MEC.	
1	7	IACCTC07-8008	2C	BA	14/04/24	24/09/25	2,77	2,77	1-MO.	106,0	293,62	62	1,5	MEC.	
1	8	CTC2994	2C	BA	13/04/24	24/09/25	9,45	9,45	1-MO.	106,0	1.001,70	62	1,5	MEC.	
1	9	CTC2994	2C	C	10/04/24	24/09/25	18,09	18,09	1-MO.	106,0	1.917,54	62	1,5	MEC.	
1	10	CTC2994	2C	C	11/04/24	24/09/25	24,17	24,17	1-MO.	106,0	2.562,02	62	1,5	MEC.	
1	11	CTC2994	2C	C	09/04/24	24/09/25	19,88	19,88	1-MO.	106,0	2.107,28	62	1,5	MEC.	
1	12	CTC2994	2C	B	12/04/24	24/09/25	21,49	21,49	1-MO.	106,0	2.277,94	62	1,5	MEC.	
1	13	CTC2994	2C	B	12/04/24	24/09/25	11,50	11,50	1-MO.	106,0	1.219,00	62	1,5	MEC.	
1	14	CTC2994	2C	B	31/07/24	24/09/25	1,98	1,98	1-MO.	106,0	209,88	62	1,5	MEC.	
1	15	CTC2994	2C	BA	12/04/24	24/09/25	0,20	0,20	1-MO.	106,0	21,20	62	1,5	MEC.	
1	16	CTC2	2C	BA	13/02/24	05/06/25	7,62	7,62	1-MO.	115,0	876,30	62	1,5	MEC.	
1	17	CTC2	2C	C	12/02/24	05/06/25	35,53	35,53	1-MO.	115,0	4.085,95	62	1,5	MEC.	
1	18	CTC2	2C	BA	10/02/24	05/06/25	17,60	17,60	1-MO.	115,0	2.024,00	62	1,5	MEC.	
1	19	CTC2	2C	BA	10/02/24	05/06/25	11,62	11,62	1-MO.	115,0	1.336,30	62	1,5	MEC.	
1	20	CTC2	2C	BA	13/02/24	05/06/25	6,97	6,97	1-MO.	115,0	801,55	62	1,5	MEC.	
1	21	CTC2	2C	BA	14/02/24	05/06/25	6,14	6,14	1-MO.	115,0	706,10	62	1,5	MEC.	
1	22	CTC2	2C	BA	13/03/24	05/06/25	7,48	7,48	1-MO.	115,0	860,20	62	1,5	MEC.	
1	23	CTC2	2C	BA	13/03/24	05/06/25	4,83	4,83	1-MO.	115,0	555,45	62	1,5	MEC.	
1	24	CTC2	2C	C	15/03/24	05/06/25	3,86	3,86	1-MO.	115,0	443,90	62	1,5	MEC.	
1	25	CTC2	2C	C	08/03/24	16/06/25	16,80	16,80	1-MO.	115,0	1.932,00	62	1,5	MEC.	
1	26	CTC2	2C	C	14/03/24	05/06/25	11,36	11,36	1-MO.	115,0	1.306,40	62	1,5	MEC.	
1	27	CTC2994	2C	BA	13/03/24	10/09/25	8,40	8,40	1-MO.	100,0	840,00	62	1,5	MEC.	
1	28	CTC2994	2C	C	12/03/24	10/09/25	6,89	6,89	1-MO.	100,0	689,00	62	1,5	MEC.	
1	29	CTC2994	2C	BA	14/03/24	10/09/25	9,51	9,51	1-MO.	100,0	951,00	62	1,5	MEC.	
1	30	CTC2994	2C	B	15/03/24	10/09/25	4,92	4,92	1-MO.	100,0	492,00	62	1,5	MEC.	
1	31	IACSP01-5503	2C	C	11/03/24	30/06/25	4,24	4,24	1-MO.	108,0	457,92	62	1,5	MEC.	
1	32	IACSP01-5503	2C	C	13/03/24	30/06/25	10,08	10,08	1-MO.	108,0	1.088,64	62	1,5	MEC.	
1	33	IACSP01-5503	2C	C	12/03/24	30/06/25	4,79	4,79	1-MO.	108,0	517,32	62	1,5	MEC.	
1	34	IACSP01-5503	2C	C	12/03/24	30/06/25	5,83	5,83	1-MO.	108,0	629,64	62	1,5	MEC.	
1	35	IACSP01-5503	2C	C	11/03/24	30/06/25	5,58	5,58	1-MO.	108,0	602,64	62	1,5	MEC.	

Caderno de Mapas

Bloco	Talhao	Variedade	Estágio de Corte	Amb. Prod.	Data Plantio	Data Último Corte	Área (ha)	Estimativas Área (ha)	Estimativas Finalid	Estimativas Produt.	Prod. Total	Dist.	Esp.	Tipo Corte	Experimento
1	36	CTC2	2C	C	29/02/24	16/06/25	9,68	9,68	1-MO.	108,0	1.045,44	62	1,5	MEC.	
1	37	CTC2	2C	C	13/03/24	16/06/25	11,31	11,31	1-MO.	108,0	1.221,48	62	1,5	MEC.	
1	38	CTC2	2C	C	29/02/24	16/06/25	5,09	5,09	1-MO.	108,0	549,72	62	1,5	MEC.	
1	39	CTC2	2C	C	29/02/24	16/06/25	2,11	2,11	1-MO.	108,0	227,88	62	1,5	MEC.	
1	40	CTC2	2C	BA	27/02/24	16/06/25	28,77	28,77	1-MO.	108,0	3.107,16	62	1,5	MEC.	
1	41	CTC2	2C	C	28/02/24	16/06/25	10,71	10,71	1-MO.	108,0	1.156,68	62	1,5	MEC.	
1	42	CTC2994	2C	B	20/03/24	20/08/25	29,36	29,36	1-MO.	95,0	2.789,20	62	1,5	MEC.	
1	43	CTC2994	2C	B	26/03/24	20/08/25	16,43	16,43	1-MO.	95,0	1.560,85	62	1,5	MEC.	
1	44	CTC2994	2C	BA	31/03/24	20/08/25	30,95	30,95	1-MO.	95,0	2.940,25	62	1,5	MEC.	
1	45	RB985476	2C	B	15/03/24	27/08/25	10,88	10,88	1-MO.	100,0	1.088,00	62	1,5	MEC.	
1	46	RB985476	2C	C	15/03/24	27/08/25	7,74	7,74	1-MO.	100,0	774,00	62	1,5	MEC.	
1	47	RB985476	2C	C	18/03/24	27/08/25	5,11	5,11	1-MO.	100,0	511,00	62	1,5	MEC.	
1	48	RB985476	2C	C	18/03/24	27/08/25	2,45	2,45	1-MO.	100,0	245,00	62	1,5	MEC.	
1	49	CTC2994	2C	B	13/03/24	24/09/25	5,36	5,36	1-MO.	96,0	514,56	62	1,5	MEC.	
1	50	CTC2994	2C	C	12/03/24	24/09/25	7,23	7,23	1-MO.	96,0	694,08	62	1,5	MEC.	
1	51	CTC2994	2C	C	09/04/24	24/09/25	5,28	5,28	1-MO.	96,0	506,88	62	1,5	MEC.	
1	52	RB985476	2C	C	05/04/24	27/08/25	18,53	18,53	1-MO.	93,0	1.723,29	62	1,5	MEC.	
1	53	RB985476	2C	C	25/03/24	27/08/25	2,07	2,07	1-MO.	93,0	192,51	62	1,5	MEC.	
1	54	RB985476	2C	B	25/03/24	27/08/25	3,84	3,84	1-MO.	93,0	357,12	62	1,5	MEC.	
1	55	RB985476	2C	B	23/03/24	27/08/25	13,54	13,54	1-MO.	93,0	1.259,22	62	1,5	MEC.	
1	56	RB985476	2C	B	21/03/24	27/08/25	8,58	8,58	1-MO.	93,0	797,94	62	1,5	MEC.	
1	57	RB985476	2C	C	20/03/24	27/08/25	15,59	15,59	1-MO.	93,0	1.449,87	62	1,5	MEC.	
1	58	IACCTC07-8008	2C	C	15/04/24	15/08/25	9,72	9,72	1-MO.	93,0	903,96	62	1,5	MEC.	
1	59	IACCTC07-8008	2C	C	17/04/24	15/08/25	11,26	11,26	1-MO.	93,0	1.047,18	62	1,5	MEC.	
1	60	IACCTC07-8008	2C	C	16/04/24	15/08/25	1,95	1,95	1-MO.	93,0	181,35	62	1,5	MEC.	
1	61	IACCTC07-8008	2C	C	18/04/24	15/08/25	4,00	4,00	1-MO.	93,0	372,00	62	1,5	MEC.	
1	62	IACCTC07-8008	2C	C	18/04/24	15/08/25	3,44	3,44	1-MO.	93,0	319,92	62	1,5	MEC.	
1	63	IACCTC07-8008	2C	C	16/04/24	15/08/25	4,34	4,34	1-MO.	93,0	403,62	62	1,5	MEC.	
1	64	IACCTC07-8008	2C	C	16/04/24	15/08/25	4,13	4,13	1-MO.	93,0	384,09	62	1,5	MEC.	
1	65	IACCTC07-8008	2C	C	17/04/24	15/08/25	10,59	10,59	1-MO.	93,0	984,87	62	1,5	MEC.	
1	66	IACCTC07-8008	2C	A	18/04/24	15/08/25	4,78	4,78	1-MO.	93,0	444,54	62	1,5	MEC.	
1	67	IACCTC07-8008	2C	D	18/04/24	15/08/25	5,24	5,24	1-MO.	93,0	487,32	62	1,5	MEC.	
1	68	IACCTC07-8008	2C	D	18/04/24	15/08/25	0,88	0,88	1-MO.	93,0	81,84	62	1,5	MEC.	
1	69	IACCTC07-8008	2C	A	20/04/24	15/08/25	7,13	7,13	1-MO.	93,0	663,09	62	1,5	MEC.	
1	70	IACCTC07-8008	2C	D	18/04/24	15/08/25	1,57	1,57	1-MO.	93,0	146,01	62	1,5	MEC.	
1	71	IACCTC07-8008	2C	D	16/04/24	15/08/25	13,45	13,45	1-MO.	93,0	1.250,85	62	1,5	MEC.	
1	72	CTC2994	2C	B	19/04/24	24/09/25	6,40	6,40	1-MO.	95,0	608,00	62	1,5	MEC.	
1	73	CTC2994	2C	B	19/04/24	24/09/25	2,76	2,76	1-MO.	95,0	262,20	62	1,5	MEC.	
1	74	CTC2994	2C	B	19/04/24	24/09/25	9,03	9,03	1-MO.	95,0	857,85	62	1,5	MEC.	
1	75	CTC2994	2C	B	20/04/24	23/10/25	4,27	4,27	1-MO.	95,0	405,65	62	1,5	MEC.	
1	75	IACCTC07-8008	2C	B	20/04/24	23/10/25	1,00	1,00	1-MO.	95,0	95,00	62	1,5	MEC.	

Caderno de Mapas

Bloco	Talhao	Variedade	Estágio de Corte	Amb. Prod.	Data Plantio	Data Último Corte	Área (ha)	Estimativas Área (ha)	Estimativas Finalid	Estimativas Produt.	Prod. Total	Dist.	Esp.	Tipo Corte	Experimento
1	76	CTC2994	2C	B	20/04/24	23/10/25	4,01	4,01	1-MO.	95,0	380,95	62	1,5	MEC.	
1	77	CTC2994	2C	B	20/04/24	23/10/25	12,20	12,20	1-MO.	95,0	1.159,00	62	1,5	MEC.	
1	78	CTC2994	2C	B	19/04/24	23/10/25	5,39	5,39	1-MO.	95,0	512,05	62	1,5	MEC.	
Total/Média (1 / 117 · BOM JARDIM)							785,48	785,48		103,0	80.891,46				

N: 7713436.867
E: 348307.1819
LAT: −20°40'21.7688" (−20.67271355)
LONG: −46°27'24.0994" (−46.45669428)

50.0 0 50.0 100.0
METROS

N
W E
S

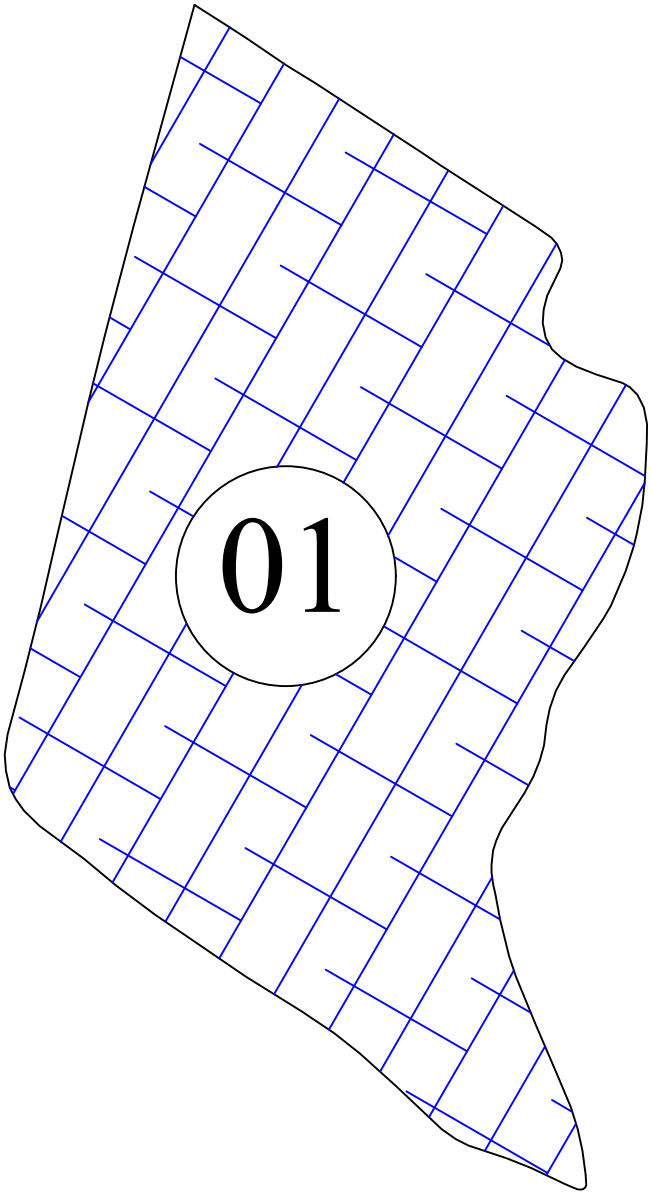

RB 98-7935

TABELA DE VARIEDADE	
VARIEDADE	ÁREA
RB987935	4,53
Total Geral	**4,53**

IPIRANGA AGROINDUSTRIAL

PROJETO CADERNO DE MAPA 26'27	DATA 05/03/2026	ESCALA 1:5000	TOPÓGRAFO CRISTIAN
FAZENDA 118 - TAQUARUSSU II	MUNICÍPIO PASSOS - MG		ÁREA (ha) 4,53
PROPRIETÁRIO AGROPRCUARIA VALE DO RIO GRANDE	UNIDADE IPIRANGA PASSOS - MG		CÓDIGO 118

Caderno de Mapas

Bloco	Talhao	Variedade	Estágio de Corte	Amb. Prod.	Data Plantio	Data Último Corte	Área (ha)	Estimativas Área (ha)	Estimativas Finalid	Estimativas Produt.	Prod. Total	Dist.	Esp.	Tipo Corte	Experimento
1 · REG 1			**118 · TAQUARUSSU II**				**IPIRANGA AGROINDUSTRIAL S.A**								
1	1	RB987935	2C	C	19/01/24	02/10/25	4,53	4,53	1-MO.	80,0	362,40	16	1,5	MEC.	
Total/Média (1 / 118 · TAQUARUSSU II)							4,53	4,53		80,0	362,40				

N: 7713853.634
E: 335030.8915
LAT: −20°40'4.1716" (−20.66782545)
LONG: −46°35'2.6806" (−46.58407794)

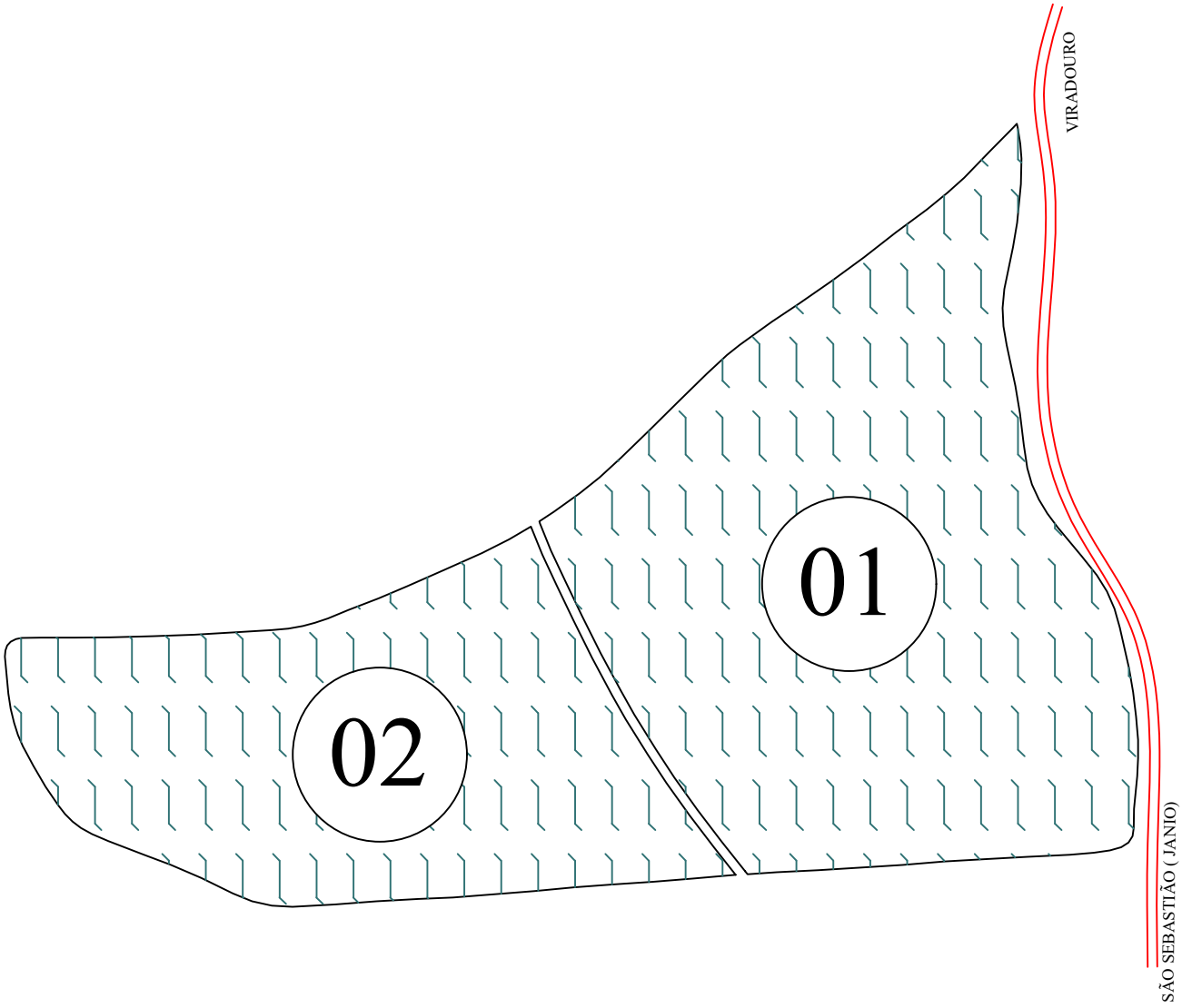

CTC - 9009

TABELA DE VARIENDADE	
VARIEDADE	ÁREA
CTC9003	11,50
TOTAL	**11,50**

IPIRANGA AGROINDUSTRIAL

PROJETO: CADERNO DE MAPA 26'27	DATA: 05/03/2026	ESCALA: 1:5000	TOPÓGRAFO: CRISTIAN
FAZENDA: 119 - GROTÃO	MUNICÍPIO: PASSOS - MG		ÁREA (ha): 11,50
PROPRIETÁRIO: FÁBIO ABREU LEMOS BRANDÃO	UNIDADE: IPIRANGA PASSOS S.A.		CÓDIGO: 119

Caderno de Mapas

Bloco	Talhao	Variedade	Estágio de Corte	Amb. Prod.	Data Plantio	Data Último Corte	Área (ha)	Estimativas Área (ha)	Estimativas Finalid	Estimativas Produt.	Prod. Total	Dist.	Esp.	Tipo Corte	Experimento
1 · REG 1			**119 · GROTÃO**				**IPIRANGA AGROINDUSTRIAL S.A**								
1	1	CTC9003	3C	B	16/04/23	07/11/25	6,99	6,99	1-MO.	78,0	545,22	20,2	1,5	MEC.	
1	2	CTC9003	3C	B	17/04/23	07/11/25	4,51	4,51	1-MO.	78,0	351,78	20,2	1,5	MEC.	
Total/Média (1 / 119 · GROTÃO)							11,50	11,50		78,0	897,00				

N: 7713853.634
E: 335030.8915
LAT: −20°40'4.1716" (−20.66782545)
LONG: −46°35'2.6806" (−46.58407794)

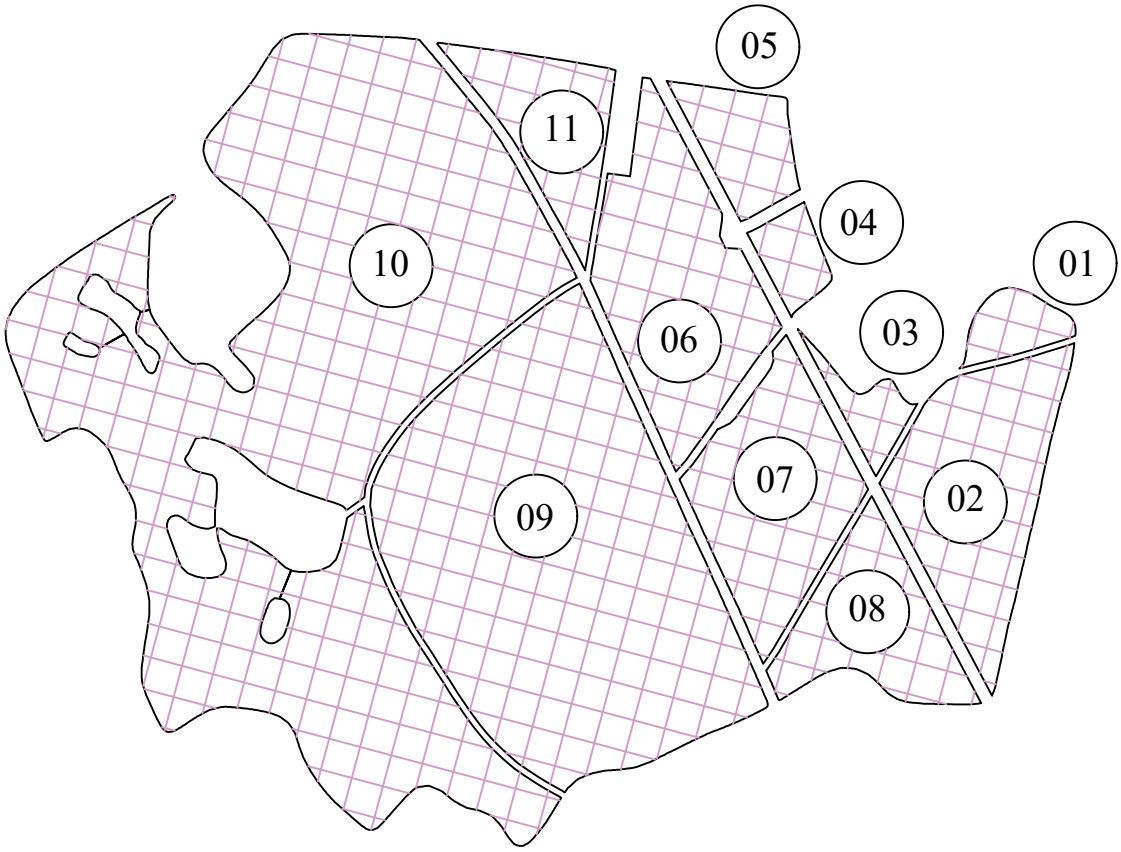

IAC CTC 07-7207

TABELA DE VARIEDADE	
VARIEDADE	ÁREA
IACCTC07-7207	29,28
Total Geral	**29,28**

PROJETO: CADERNO DE MAPA 26'27	DATA: 05/03/2026	ESCALA: 1:5000	TOPÓGRAFO: CRISTIAN
FAZENDA: 120 - SÃO JOSÉ DA BOCAINA II	MUNICÍPIO: PASSOS - MG		ÁREA (ha): 29,28
PROPRIETÁRIO: ICLEIA PIANTINO	UNIDADE: IPIRANGA PASSOS S.A.		

IPIRANGA AGROINDUSTRIAL

Caderno de Mapas

Bloco	Talhao	Variedade	Estágio de Corte	Amb. Prod.	Data Plantio	Data Último Corte	Área (ha)	Estimativas Área (ha)	Estimativas Finalid	Estimativas Produt.	Prod. Total	Dist.	Esp.	Tipo Corte	Experimento
1 · REG 1			**120 · S J BOCAINA II**				**IPIRANGA AGROINDUSTRIAL S.A**								
1	1	IACCTC07-7207	1C	A	14/01/25	13/01/26	0,33	0,33	2-MU.	70,0	23,10	14	1,5	MEC.	
1	2	IACCTC07-7207	1C	A	14/01/25	04/04/26	2,06	1,11	2-MU.	70,0	77,70	14	1,5	MEC.	
1	2	IACCTC07-7207	1C	A	14/01/25	04/04/26	2,06	0,95	1-MO.	93,0	88,35	14	1,5	MEC.	
1	3	IACCTC07-7207	1C	B	14/01/25	13/01/26	0,28	0,28	2-MU.	70,0	19,60	14	1,5	MEC.	
1	4	IACCTC07-7207	1C	B	14/01/25	13/01/26	0,31	0,31	2-MU.	70,0	21,70	14	1,5	MEC.	
1	5	IACCTC07-7207	1C	B	14/01/25	13/01/26	0,64	0,64	2-MU.	70,0	44,80	14	1,5	MEC.	
1	6	IACCTC07-7207	1C	B	14/01/25	04/04/26	2,25	2,25	1-MO.	93,0	209,25	14	1,5	MEC.	
1	7	IACCTC07-7207	1C	B	14/01/25	04/04/26	1,82	1,82	1-MO.	93,0	169,26	14	1,5	MEC.	
1	8	IACCTC07-7207	1C	A	14/01/25	04/04/26	1,26	1,26	1-MO.	93,0	117,18	14	1,5	MEC.	
1	9	IACCTC07-7207	1C	B	14/01/25	04/04/26	7,03	7,03	1-MO.	100,0	703,00	14	1,5	MEC.	
1	10	IACCTC07-7207	1C	CB	17/01/25	04/04/26	12,28	12,28	1-MO.	100,0	1.228,00	14	1,5	MEC.	
1	11	IACCTC07-7207	1C	B	21/01/25	04/04/26	1,02	1,02	1-MO.	93,0	94,86	14	1,5	MEC.	
Total/Média (1 / 120 · S J BOCAINA II)							29,28	29,28		95,5	2.796,80				

N: 7726949.35548960
E: 322493.48645906
LAT: −20°32'54.2292453" (−20.54839701258)
LONG: −46°42'11.0979607" (−46.70308276687)

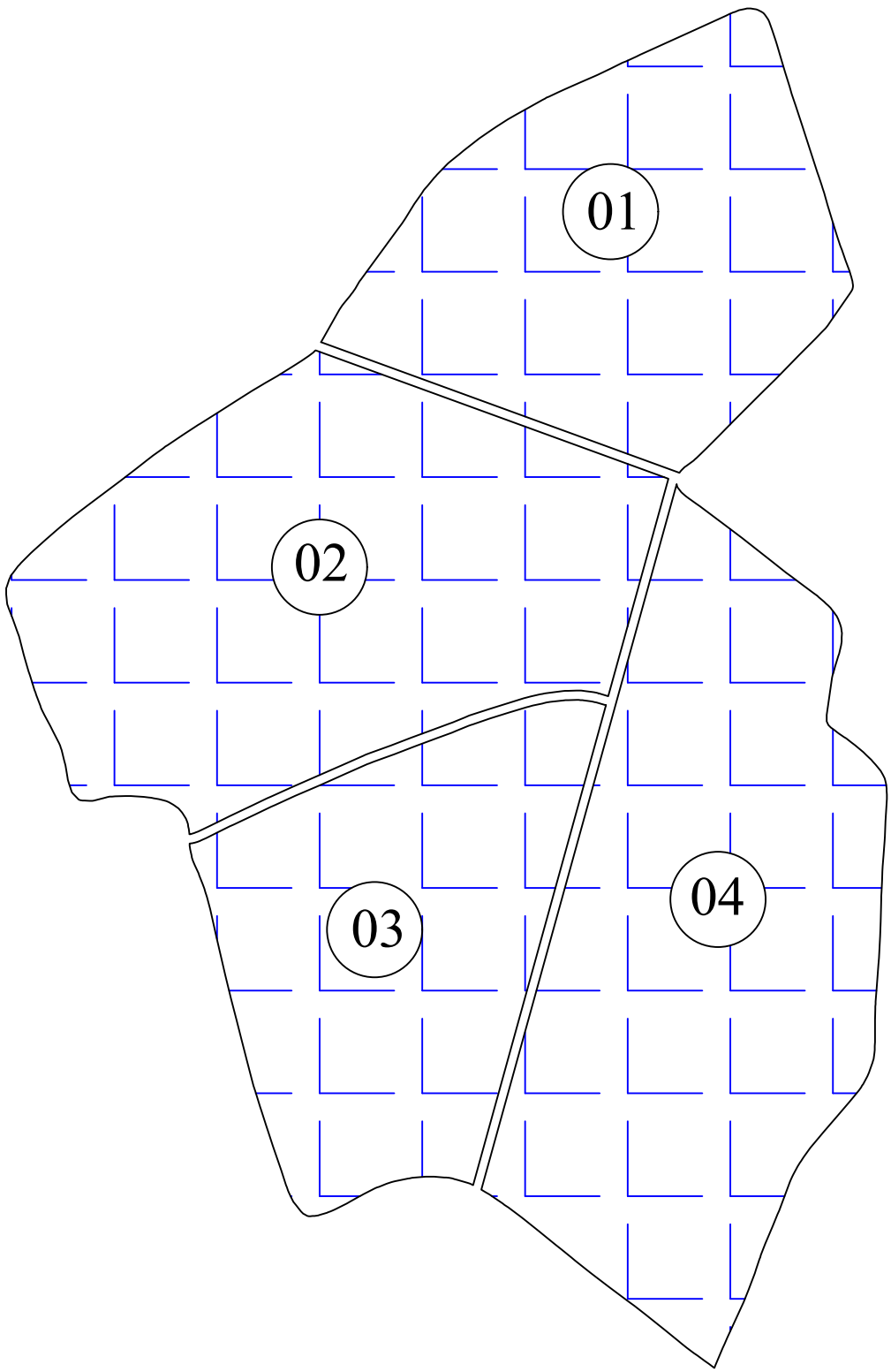

CTC - 2

TABELA DE VARIEDADE	
VARIEDADE	ÁREA
CTC2	19,64
Total Geral	**19,64**

IPIRANGA AGROINDUSTRIAL	PROJETO: CADERNO DE MAPA 26'27	DATA: 05/03/2026	ESCALA: 1:5000	TOPÓGRAFO: CRISTIAN
	FAZENDA: 121 - BARRINHA III	MUNICÍPIO: PASSOS - MG		ÁREA (ha): 19,64
	PROPRIETÁRIO:	UNIDADE: IPIRANGA PASSOS - MG		CÓDIGO: 121

Caderno de Mapas

Bloco	Talhao	Variedade	Estágio de Corte	Amb. Prod.	Data Plantio	Último Corte	Área (ha)	Estimativas Área (ha)	Finalid	Produt.	Prod. Total	Dist.	Esp.	Tipo Corte	Experimento
1 · REG 1			**121 · BARRINHA III**				**IPIRANGA AGROINDUSTRIAL S.A**								
1	1	CTC2	1C	A	29/01/25	15/05/26	4,15	4,15	1-MO.	130,0	539,50	31	1,5	MEC.	
1	2	CTC2	1C	A	28/01/25	15/05/26	5,74	5,74	1-MO.	130,0	746,20	31	1,5	MEC.	
1	3	CTC2	1C	A	02/02/25	15/05/26	3,74	3,74	1-MO.	130,0	486,20	31	1,5	MEC.	
1	4	CTC2	1C	A	28/01/25	15/05/26	6,01	6,01	1-MO.	130,0	781,30	31	1,5	MEC.	
Total/Média (1 / 121 · BARRINHA III)							19,64	19,64		130,0	2.553,20				

N: 7713853.634
E: 335030.8915
LAT: −20°40'4.1716" (−20.66782545)
LONG: −46°35'2.6806" (−46.58407794)

50.0 0 50.0 100.0
METROS

N
W E
S

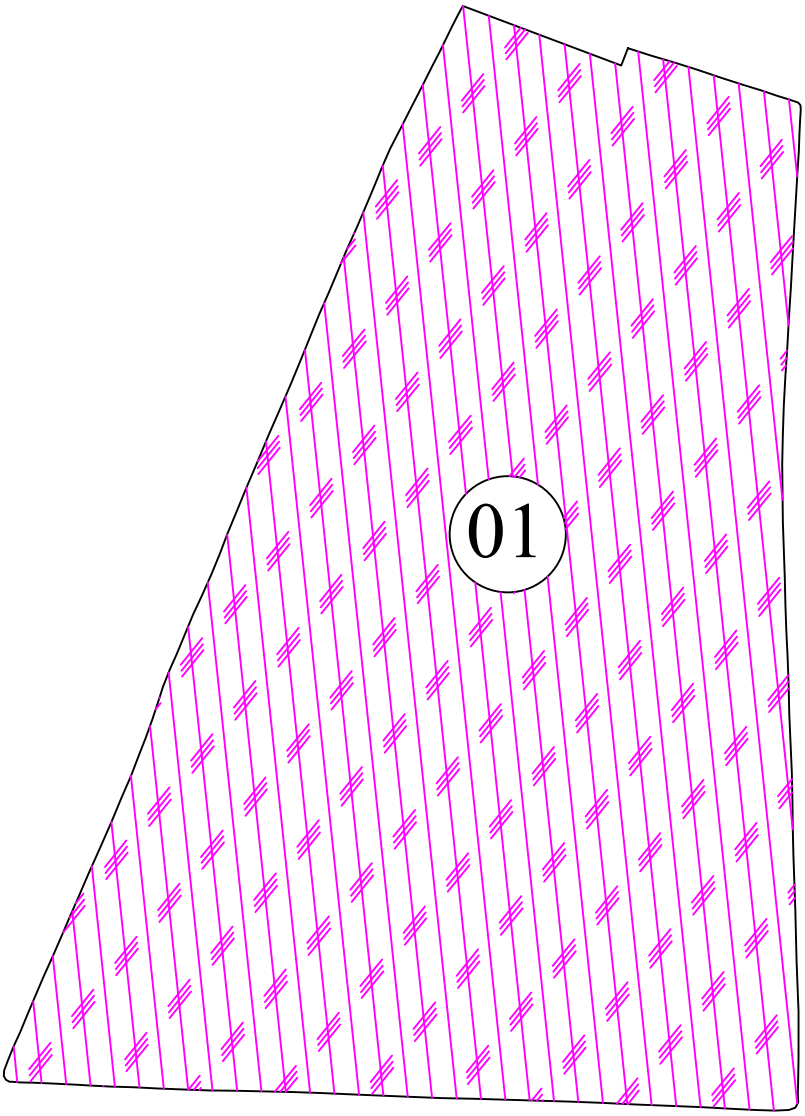

CTC-2994

TABELA DE VARIEDADE	
VARIEDADE	ÁREA
CTC2994	20,03
Total Geral	**20,03**

IPIRANGA AGROINDUSTRIAL

PROJETO: CADERNO DE MAPA 26'27	DATA: 05/03/2026	ESCALA: 1:5000	TOPÓGRAFO: CRISTIAN
FAZENDA: 122 - ESTIVA II	MUNICÍPIO: PASSOS - MG		ÁREA (ha): 20,03
PROPRIETÁRIO: MIGUEL ANGELO DE PAULA ANDRADE	UNIDADE: IPIRANGA PASSOS S.A.		

Caderno de Mapas

Bloco	Talhao	Variedade	Estágio de Corte	Amb. Prod.	Data Plantio	Data Último Corte	Área (ha)	Estimativas Área (ha)	Estimativas Finalid	Estimativas Produt.	Prod. Total	Dist.	Esp.	Tipo Corte	Experimento
1 · REG 1			**122 · ESTIVA II**				**IPIRANGA AGROINDUSTRIAL S.A**								
1	1	CTC2994	1C	B	20/01/25	19/02/26	20,03	20,03	2-MU.	60,0	1.201,80	28	1,5	MEC.	
Total/Média (1 / 122 · ESTIVA II)							20,03	20,03		60,0	1.201,80				

N: 7713853.634
E: 335030.8915
LAT: −20°40'4.1716" (−20.66782545)
LONG: −46°35'2.6806" (−46.58407794)

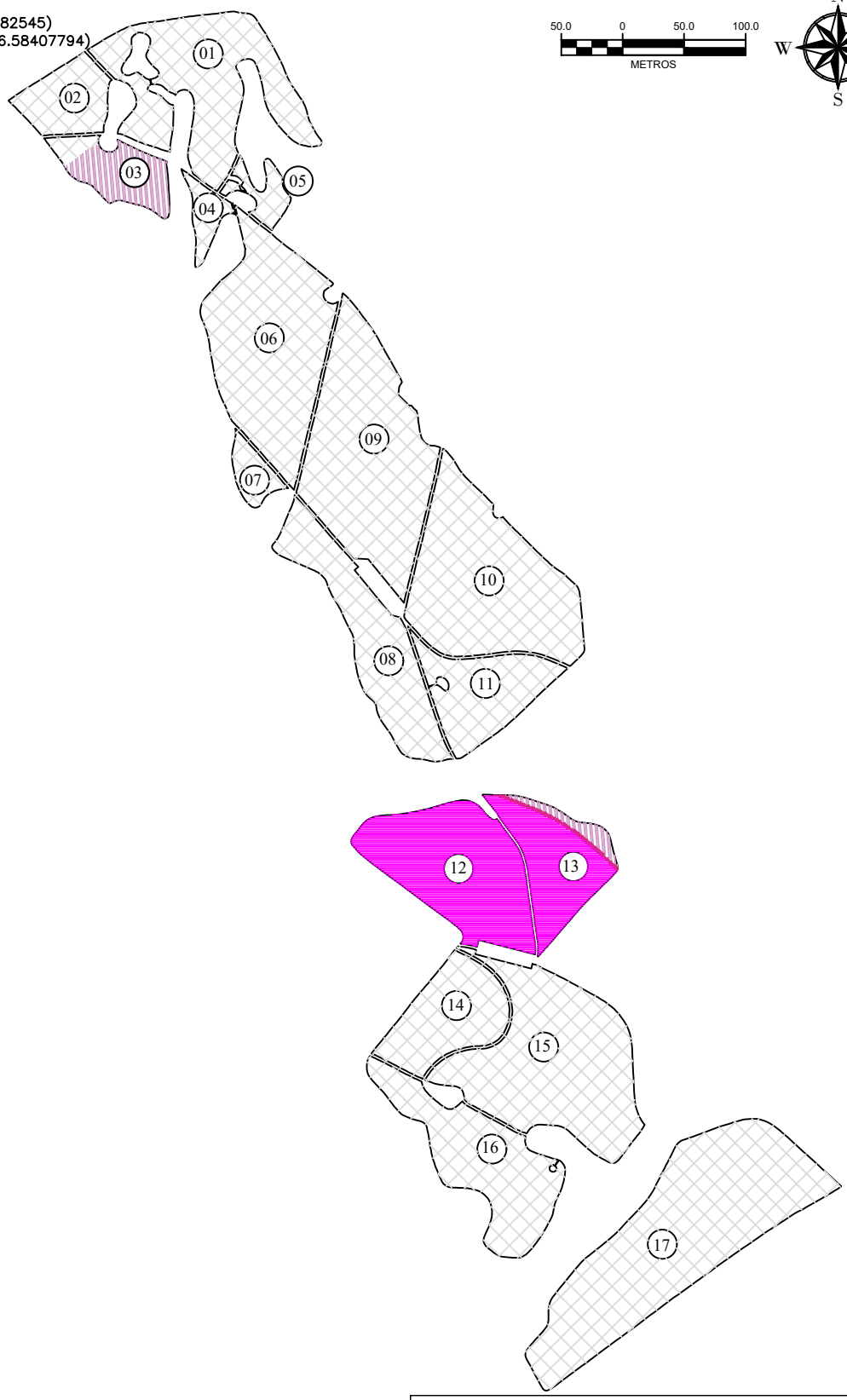

CTC - 4
RB 07-5322
RB 99-1532
RB 92-8064

TABELA DE VARIEDADE

VARIEDADE	ÁREA
CTC4	59,04
RB075322	1,74
RB928064	7,28
RB991532	0,15
Total Geral	**68,21**

IPIRANGA AGROINDUSTRIAL

PROJETO: CADERNO DE MAPA 26'27	DATA: 05/03/2026	ESCALA: 1:5000	TOPÓGRAFO: CRISTIAN
FAZENDA: 123 - SANTO ANTÔNIO III	MUNICÍPIO: PASSOS - MG		ÁREA (ha): 68,21
PROPRIETÁRIO: AGENOR	UNIDADE: IPIRANGA PASSOS S.A.		

Caderno de Mapas

Bloco	Talhao	Variedade	Estágio de Corte	Amb. Prod.	Data Plantio	Data Último Corte	Área (ha)	Estimativas Área (ha)	Estimativas Finalid	Estimativas Produt.	Prod. Total	Dist.	Esp.	Tipo Corte	Experimento
1 · REG 1			**123 · STO ANT. III**				**IPIRANGA AGROINDUSTRIAL S.A**								
1	1	CTC4	1C	BA	05/03/25	11/05/26	5,54	5,54	1-MO.	110,0	609,40	15	1,5	MEC.	
1	2	CTC4	1C	BA	06/03/25	11/05/26	1,61	1,61	1-MO.	110,0	177,10	15	1,5	MEC.	
1	3	CTC4	2C	BA	04/03/25	11/05/26	0,28	0,23	2-MU.	70,0	16,10	15	1,5	MEC.	
1	3	CTC4	2C	BA	04/03/25	11/05/26	0,28	0,05	1-MO.	110,0	5,50	15	1,5	MEC.	
1	3	RB075322	2C	BA	04/03/25	11/05/26	1,38	1,16	2-MU.	70,0	81,20	15	1,5	MEC.	
1	3	RB075322	2C	BA	04/03/25	11/05/26	1,38	0,22	1-MO.	110,0	24,20	15	1,5	MEC.	
1	4	CTC4	1C	BA	04/03/25	11/05/26	0,57	0,57	1-MO.	110,0	62,70	15	1,5	MEC.	
1	5	CTC4	1C	BA	28/02/25	11/05/26	0,60	0,60	1-MO.	110,0	66,00	15	1,5	MEC.	
1	6	CTC4	1C	BA	27/02/25	11/05/26	6,42	6,42	1-MO.	110,0	706,20	15	1,5	MEC.	
1	7	CTC4	1C	BA	03/03/25	11/05/26	0,62	0,62	1-MO.	110,0	68,20	15	1,5	MEC.	
1	8	CTC4	1C	BA	01/03/25	11/05/26	3,90	3,90	1-MO.	110,0	429,00	15	1,5	MEC.	
1	9	CTC4	1C	BA	28/02/25	11/05/26	7,03	7,03	1-MO.	110,0	773,30	15	1,5	MEC.	
1	10	CTC4	1C	BA	22/02/25	11/05/26	6,59	6,59	1-MO.	110,0	724,90	15	1,5	MEC.	
1	11	CTC4	1C	BA	24/02/25	11/05/26	2,63	2,63	1-MO.	120,0	315,60	15	1,5	MEC.	
1	12	RB928064	1C	BA	20/02/25	11/05/26	4,91	4,91	1-MO.	110,0	540,10	15	1,5	MEC.	
1	13	RB075322	2C	BA	20/02/25	11/05/26	0,36	0,32	1-MO.	110,0	35,20	15	1,5	MEC.	
1	13	RB075322	2C	BA	20/02/25	11/05/26	0,36	0,04	2-MU.	70,0	2,80	15	1,5	MEC.	
1	13	RB928064	2C	BA	20/02/25	11/05/26	2,37	0,28	2-MU.	70,0	19,60	15	1,5	MEC.	
1	13	RB928064	2C	BA	20/02/25	11/05/26	2,37	2,09	1-MO.	110,0	229,90	15	1,5	MEC.	
1	13	VIVEIRO	2C	BA	20/02/25	11/05/26	0,15	0,02	2-MU.	70,0	1,40	15	1,5	MEC.	
1	13	VIVEIRO	2C	BA	20/02/25	11/05/26	0,15	0,13	1-MO.	110,0	14,30	15	1,5	MEC.	
1	14	CTC4	1C	A	21/02/25	11/05/26	2,74	2,74	1-MO.	120,0	328,80	15	1,5	MEC.	
1	15	CTC4	1C	BA	19/02/25	11/05/26	6,99	6,99	1-MO.	120,0	838,80	15	1,5	MEC.	
1	16	CTC4	1C	NC	24/02/25	11/05/26	4,18	4,18	1-MO.	120,0	501,60	15	1,5	MEC.	
1	17	CTC4	1C	B	20/02/25	11/05/26	9,34	9,34	1-MO.	120,0	1.120,80	15	1,5	MEC.	
Total/Média (1 / 123 · STO ANT. III)							68,21	68,21		112,8	7.692,70				

N: 7713853.634
E: 335030.8915
LAT: −20°40'4.1716" (−20.66782545)
LONG: −46°35'2.6806" (−46.58407794)

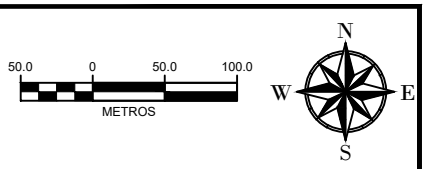

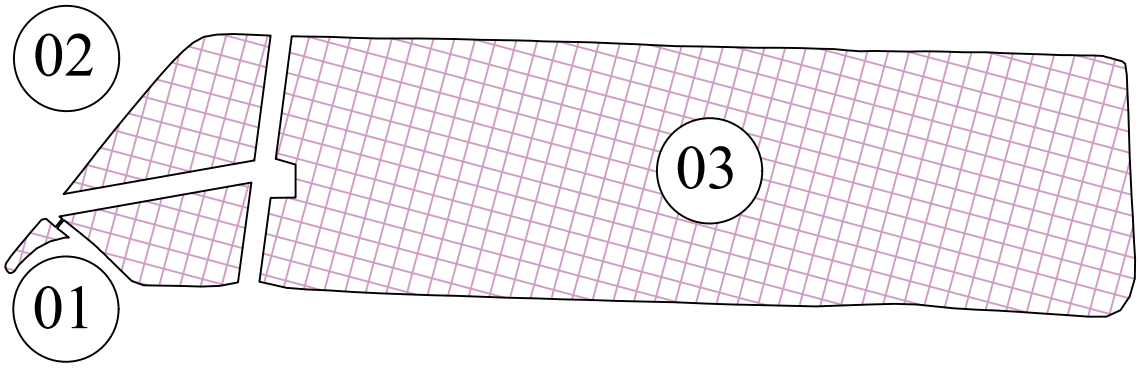

IAC CTC 07-7207

TABELA DE VARIEDADE	
VARIEDADE	ÁREA
IACCTC07-7207	5,59
Total Geral	**5,59**

IPIRANGA AGROINDUSTRIAL	PROJETO: CADERNO DE MAPA 26'27	DATA: 05/03/2026	ESCALA: 1:5000	TOPÓGRAFO: CRISTIAN
	FAZENDA: 124 - CRIMÉIA	MUNICÍPIO: PASSOS - MG		ÁREA (ha): 5,59
	PROPRIETÁRIO: ANTÔNIO ANDRADE VALLETA	UNIDADE: IPIRANGA PASSOS S.A.		

Caderno de Mapas

Bloco	Talhao	Variedade	Estágio de Corte	Amb. Prod.	Data Plantio	Último Corte	Área (ha)	Estimativas Área (ha)	Finalid	Produt.	Prod. Total	Dist.	Esp.	Tipo Corte	Experimento
1 · REG 1			**124 · CRIMEIA II**				**IPIRANGA AGROINDUSTRIAL S.A**								
1	1	IACCTC07-7207	2C	A	01/11/24	03/09/25	0,31	0,31	1-MO.	100,0	31,00	9,3	1,5	MEC.	
1	2	IACCTC07-7207	2C	A	01/11/24	03/09/25	0,39	0,39	1-MO.	100,0	39,00	9,3	1,5	MEC.	
1	3	IACCTC07-7207	2C	A	31/10/24	03/09/25	4,89	4,89	1-MO.	100,0	489,00	9,3	1,5	MEC.	
Total/Média (1 / 124 · CRIMEIA II)							5,59	5,59		100,0	559,00				

N: 7731870.22275259
E: 331756.09890608
LAT: −20°30'17.2778948" (−20.50479941521)
LONG: −46°36'49.6573481" (−46.61379370782)



TABELA DE VARIEDADE

VARIEDADE	ÁREA
IACSP01-5503	80,99
Total Geral	**80,99**

IAC SP 01-5503

IPIRANGA AGROINDUSTRIAL

PROJETO: CADERNO DE MAPA 26'27	DATA: 05/03/2026	ESCALA: 1:5000	TOPÓGRAFO: CRISTIAN
FAZENDA: 125 - CAMPO REDONDO	MUNICÍPIO: DELFINOPOLIS		ÁREA (ha): 80,99
PROPRIETÁRIO: JOÃO GUILHERME F. WHITAKER	UNIDADE: IPIRANGA PASSOS S.A.		

Caderno de Mapas

Bloco	Talhao	Variedade	Estágio de Corte	Amb. Prod.	Data Plantio	Data Último Corte	Área (ha)	Estimativas Área (ha)	Estimativas Finalid	Estimativas Produt.	Prod. Total	Dist.	Esp.	Tipo Corte	Experimento
1 · REG 1			**125 · CAMPO REDONDO**				**IPIRANGA AGROINDUSTRIAL S.A**								
1	1	IACSP01-5503	1C	NC	01/03/25	01/01/26	3,71	3,71	2-MU.	50,0	185,50	54	1,5	MEC.	
1	2	IACSP01-5503	1C	NC	01/03/25		5,52	5,52	1-MO.	126,0	695,52	54	1,5	MEC.	
1	3	IACSP01-5503	1C	B	01/03/25		8,75	8,75	1-MO.	126,0	1.102,50	54	1,5	MEC.	
1	4	IACSP01-5503	1C	B	01/03/25		2,92	2,92	1-MO.	126,0	367,92	54	1,5	MEC.	
1	5	IACSP01-5503	1C	B	02/03/25		4,27	4,27	1-MO.	126,0	538,02	54	1,5	MEC.	
1	6	IACSP01-5503	1C	B	02/03/25		4,49	4,49	1-MO.	126,0	565,74	54	1,5	MEC.	
1	7	IACSP01-5503	1C	NC	01/03/25	01/01/26	1,16	1,16	2-MU.	70,0	81,20	54	1,5	MEC.	
1	8	IACSP01-5503	1C	NC	02/03/25		4,27	4,27	1-MO.	126,0	538,02	54	1,5	MEC.	
1	9	IACSP01-5503	1C	C	07/03/25		7,34	7,34	1-MO.	126,0	924,84	54	1,5	MEC.	
1	10	IACSP01-5503	1C	NC	03/03/25	01/01/26	5,22	2,13	1-MO.	95,0	202,35	54	1,5	MEC.	
1	10	IACSP01-5503	1C	NC	03/03/25	01/01/26	5,22	3,09	2-MU.	50,0	154,50	54	1,5	MEC.	
1	11	IACSP01-5503	1C	NC	03/03/25		1,32	1,32	1-MO.	126,0	166,32	54	1,5	MEC.	
1	12	IACSP01-5503	1C	NC	03/03/25		2,37	2,37	1-MO.	126,0	298,62	54	1,5	MEC.	
1	13	IACSP01-5503	1C	B	03/03/25		1,72	1,72	1-MO.	126,0	216,72	54	1,5	MEC.	
1	14	IACSP01-5503	1C	B	04/03/25		2,91	2,91	1-MO.	126,0	366,66	54	1,5	MEC.	
1	15	IACSP01-5503	1C	B	07/03/25		4,77	4,77	1-MO.	126,0	601,02	54	1,5	MEC.	
1	16	IACSP01-5503	1C	B	07/03/25		7,09	7,09	1-MO.	126,0	893,34	54	1,5	MEC.	
1	17	IACSP01-5503	1C	B	04/03/25		1,14	1,14	1-MO.	126,0	143,64	54	1,5	MEC.	
1	18	IACSP01-5503	1C	B	07/03/25		5,39	5,39	1-MO.	126,0	679,14	54	1,5	MEC.	
1	19	IACSP01-5503	1C	B	04/03/25		1,49	1,49	1-MO.	126,0	187,74	54	1,5	MEC.	
1	20	IACSP01-5503	1C	B	12/03/25		1,38	1,38	1-MO.	126,0	173,88	54	1,5	MEC.	
1	21	IACSP01-5503	1C	B	10/03/25		1,93	1,93	1-MO.	126,0	243,18	54	1,5	MEC.	
1	22	IACSP01-5503	1C	B	10/03/25		1,58	1,58	1-MO.	126,0	199,08	54	1,5	MEC.	
1	23	IACSP01-5503	1C	B	12/03/25		0,25	0,25	1-MO.	126,0	31,50	54	1,5	MEC.	
Total/Média (1 / 125 · CAMPO REDONDO)							80,99	80,99		118,0	9.556,95				

N: 7713853.634
E: 335030.8915
LAT: −20°40'4.1716" (−20.66782545)
LONG: −46°35'2.6806" (−46.58407794)

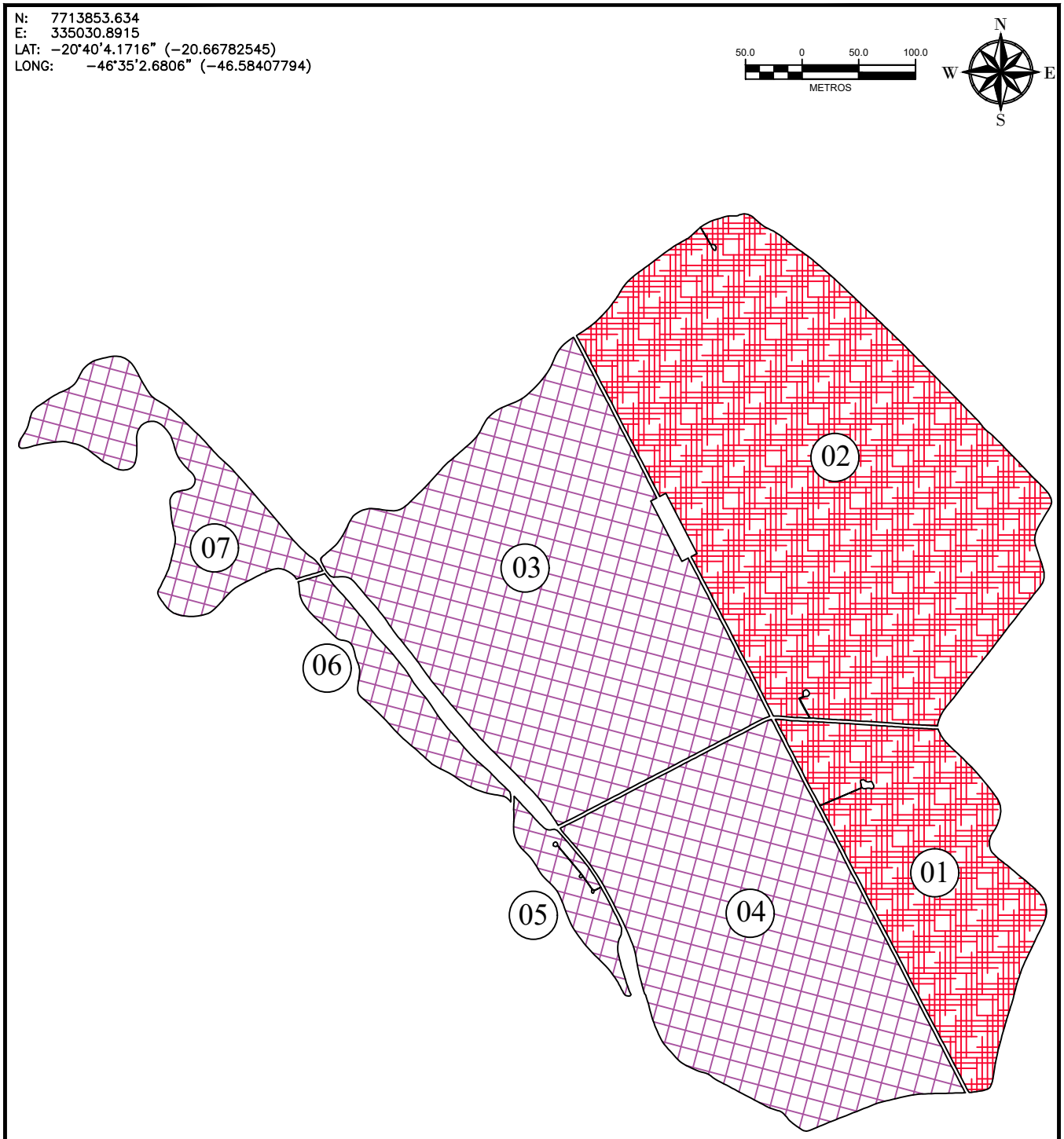

IAC CTC 07-8008
IAC SP 01-5503

TABELA DE VARIENDADE	
VARIEDADE	ÁREA
IACCTC07-8008	51,11
IACSP01-5503	41,71
TOTAL	92,82

IPIRANGA AGROINDUSTRIAL

PROJETO: CADERNO DE MAPA 26'27	DATA: 05/03/2026	ESCALA: 1:5000	TOPÓGRAFO: CRISTIAN
FAZENDA: 126 - SANTA IZAURA	MUNICÍPIO: DELFINOPOLIS - MG		ÁREA (ha): 92,82
PROPRIETÁRIO: IPIRANGA AGROINDUSTRIAL	UNIDADE: IPIRANGA PASSOS S.A.		

Caderno de Mapas

Bloco	Talhao	Variedade	Estágio de Corte	Amb. Prod.	Data Plantio	Data Último Corte	Área (ha)	Estimativas Área (ha)	Estimativas Finalid	Estimativas Produt.	Prod. Total	Dist.	Esp.	Tipo Corte	Experimento
1 · REG 1			**126 · STA.IZAURA**				**IPIRANGA AGROINDUSTRIAL S.A**								
1	1	IACSP01-5503	1C	NC	11/04/25		10,37	10,37	1-MO.	140,0	1.451,80	50,8	1,5	MEC.	
1	2	IACSP01-5503	1C	NC	09/04/25		31,34	31,34	1-MO.	140,0	4.387,60	50,8	1,5	MEC.	
1	3	IACCTC07-8008	1C	NC	16/04/25		23,27	23,27	1-MO.	140,0	3.257,80	50,8	1,5	MEC.	
1	4	IACCTC07-8008	1C	NC	16/04/25		18,88	18,88	1-MO.	140,0	2.643,20	50,8	1,5	MEC.	
1	5	IACCTC07-8008	1C	NC	22/04/25		1,47	1,47	1-MO.	140,0	205,80	50,8	1,5	MEC.	
1	6	IACCTC07-8008	1C	NC	22/04/25		2,21	2,21	1-MO.	140,0	309,40	50,8	1,5	MEC.	
1	7	IACCTC07-8008	1C	NC	22/04/25		5,28	5,28	1-MO.	140,0	739,20	50,8	1,5	MEC.	
Total/Média (1 / 126 · STA.IZAURA)							92,82	92,82		140,0	12.994,80				

N: 7713853.634
E: 335030.8915
LAT: −20°40'4.1716" (−20.66782545)
LONG: −46°35'2.6806" (−46.58407794)

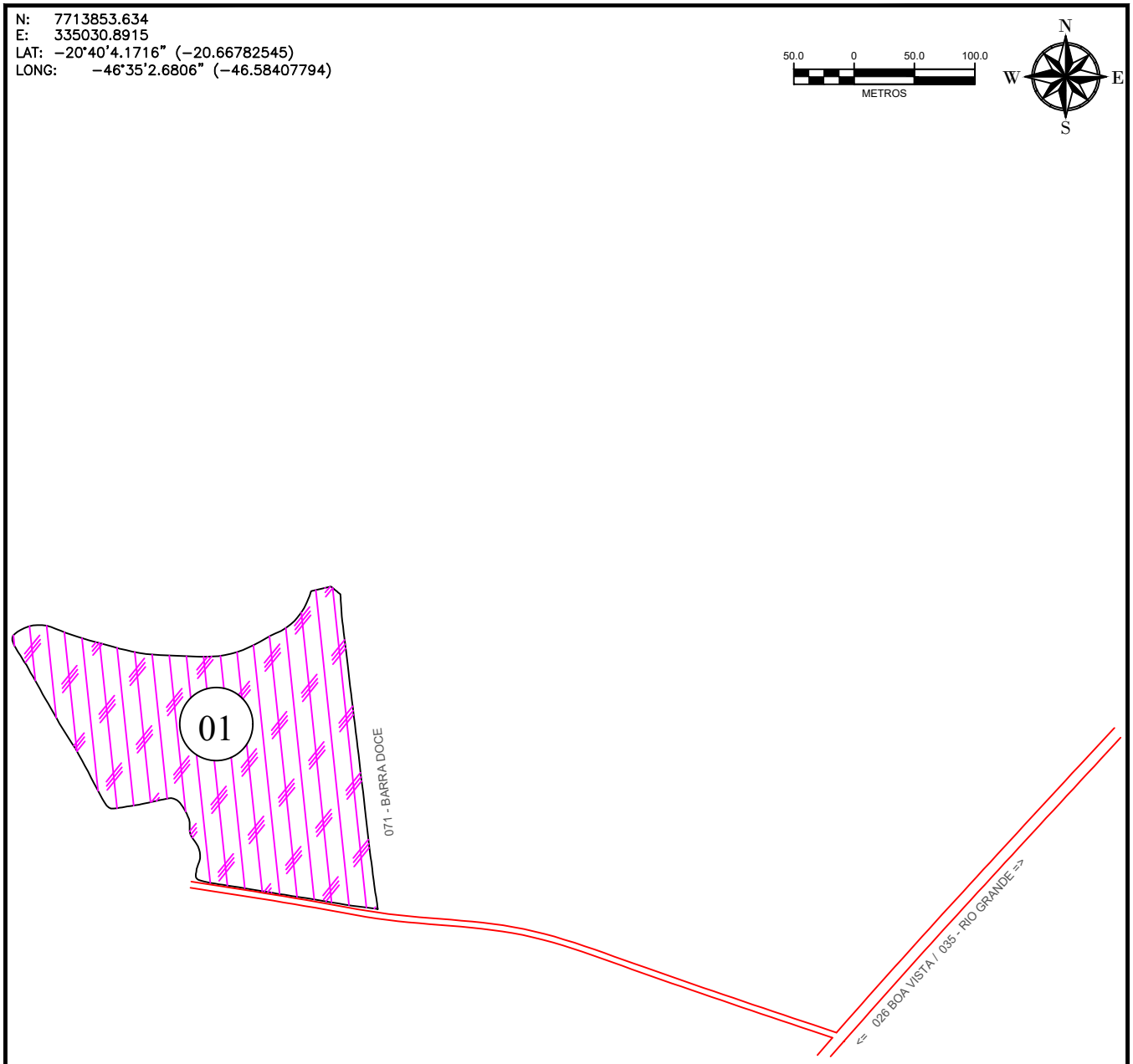

CTC -2994

TABELA DE VARIENDADE	
VARIEDADE	ÁREA
CTC2994	4,41
TOTAL	**4,41**

IPIRANGA AGROINDUSTRIAL

PROJETO: CADERNO DE MAPA 26'27	DATA: 05/03/2026	ESCALA: 1:5000	TOPÓGRAFO: CRISTIAN
FAZENDA: 127 - BARRA DOCE III	MUNICÍPIO: PASSOS - MG		ÁREA (ha): 4,41
PROPRIETÁRIO: IPIRANGA AGROINDUSTRIAL	UNIDADE: IPIRANGA PASSOS S.A.		

Caderno de Mapas

Bloco	Talhao	Variedade	Estágio de Corte	Amb. Prod.	Data Plantio	Data Último Corte	Área (ha)	Estimativas Área (ha)	Estimativas Finalid	Estimativas Produt.	Prod. Total	Dist.	Esp.	Tipo Corte	Experimento
1 · REG 1			**127 · BARRA DOCE III**				**IPIRANGA AGROINDUSTRIAL S.A**								
1	1	CTC2994	1C	IN	09/10/25		4,41	4,41	1-MO.	100,0	441,00	25	1,5	MEC.	
Total/Média (1 / 127 · BARRA DOCE III)							4,41	4,41		100,0	441,00				

N: 7726560.536
E: 337112.4145
LAT: −20°33'11.6296" (−20.55323044)
LONG: −46°33'46.5471" (−46.56292974)



TABELA DE VARIEDADE	
VARIEDADE	ÁREA
IACSP01-5503	47,93
Total Geral	**47,93**

IAC SP 01-5503

IPIRANGA AGROINDUSTRIAL

PROJETO: CADERNO DE MAPA 26'27	DATA: 21/05/2026	ESCALA: 1:5000	TOPÓGRAFO: CRISTIAN
FAZENDA: 128 - ESTIVA III	MUNICÍPIO: DELFINÓPOLIS MG		ÁREA (ha): 47,93
PROPRIETÁRIO: IPIRANGA AGROINDUSTRIAL	UNIDADE: PASSOS MG		

Caderno de Mapas

Bloco	Talhao	Variedade	Estágio de Corte	Amb. Prod.	Data Plantio	Último Corte	Área (ha)	Estimativas Área (ha)	Finalid	Produt.	Prod. Total	Dist.	Esp.	Tipo Corte	Experimento
1 · REG 1			**128 · ESTIVA III**				**IPIRANGA AGROINDUSTRIAL S.A**								
1	1	IACSP01-5503	FORM	NC	26/02/26		22,57	0,00	.		0,00	55	1,5	N/D	
1	2	IACSP01-5503	FORM	NC	25/02/26		3,09	0,00	.		0,00	55	1,5	N/D	
1	3	IACSP01-5503	FORM	NC	23/02/26		1,14	0,00	.		0,00	55	1,5	N/D	
1	4	IACSP01-5503	FORM	NC	21/02/26		2,53	0,00	.		0,00	55	1,5	N/D	
1	5	IACSP01-5503	FORM	NC	23/02/26		2,12	0,00	.		0,00	55	1,5	N/D	
1	6	IACSP01-5503	FORM	NC	20/02/26		2,35	0,00	.		0,00	55	1,5	N/D	
1	7	IACSP01-5503	FORM	NC	20/02/26		1,10	0,00	.		0,00	55	1,5	N/D	
1	8	IACSP01-5503	FORM	NC	21/02/26		1,49	0,00	.		0,00	55	1,5	N/D	
1	9	IACSP01-5503	FORM	NC	21/02/26		1,05	0,00	.		0,00	55	1,5	N/D	
1	10	IACSP01-5503	FORM	NC	21/02/26		2,89	0,00	.		0,00	55	1,5	N/D	
1	11	IACSP01-5503	FORM	NC	21/02/26		2,99	0,00	.		0,00	55	1,5	N/D	
1	12	IACSP01-5503	FORM	NC	20/02/26		2,94	0,00	.		0,00	55	1,5	N/D	
1	13	IACSP01-5503	FORM	NC	20/02/26		1,67	0,00	.		0,00	55	1,5	N/D	
Total/Média (1 / 128 · ESTIVA III)							47,93	0,00			0,00				

N: 7713853.634
E: 335030.8915
LAT: −20°40'4.1716" (−20.66782545)
LONG: −46°35'2.6806" (−46.58407794)

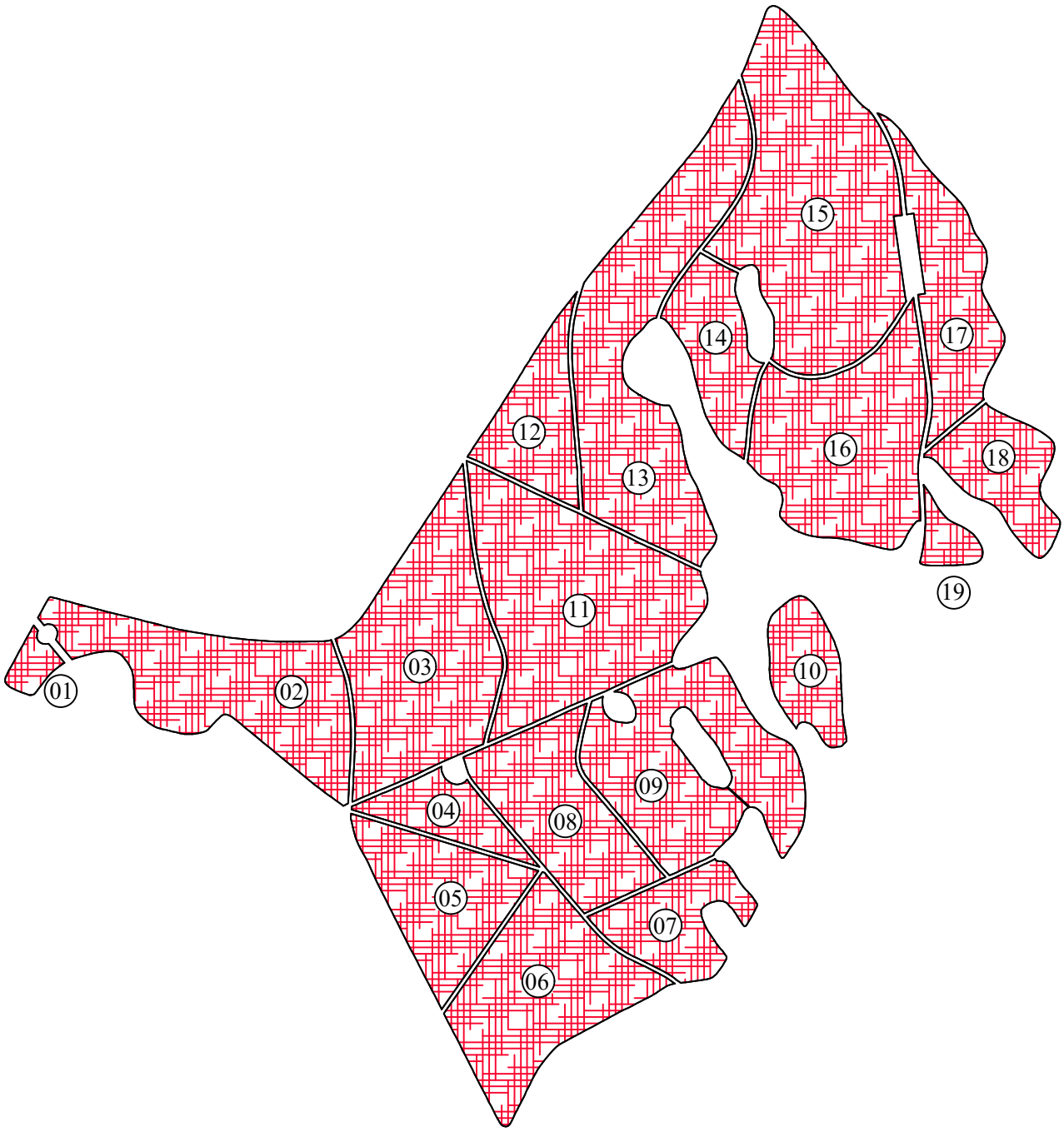

TABELA DE VARIEDADE

VARIEDADE	ÁREA
IACSP01-5503	56,40
Total Geral	**56,40**

IAC SP 01-5503

IPIRANGA AGROINDUSTRIAL

PROJETO: CADERNO DE MAPA 26'27	DATA: 21/05/2026	ESCALA: 1:5000	TOPÓGRAFO: CRISTIAN
FAZENDA: 129 - SAO SEBASTIAO IV	MUNICÍPIO: PASSOS - MG		ÁREA (ha): 56,40
PROPRIETÁRIO: IPIRANGA AGROINDUSTRIAL	UNIDADE: IPIRANGA PASSOS S.A.		

Caderno de Mapas

Bloco	Talhao	Variedade	Estágio de Corte	Amb. Prod.	Data Plantio	Último Corte	Área (ha)	Estimativas Área (ha)	Finalid	Produt.	Prod. Total	Dist.	Esp.	Tipo Corte	Experimento
1 · REG 1			**129 · S.SEBASTIAO IV**				**IPIRANGA AGROINDUSTRIAL S.A**								
1	1	IACSP01-5503	FORM	NC	27/04/26		0,31	0,00	.		0,00	16,8	1,5	N/D	
1	2	IACSP01-5503	FORM	NC	27/04/26		4,18	0,00	.		0,00	16,8	1,5	N/D	
1	3	IACSP01-5503	FORM	NC	28/04/26		4,76	0,00	.		0,00	16,8	1,5	N/D	
1	4	IACSP01-5503	FORM	NC	28/04/26		1,07	0,00	.		0,00	16,8	1,5	N/D	
1	5	IACSP01-5503	FORM	NC	27/04/26		2,50	0,00	.		0,00	16,8	1,5	N/D	
1	6	IACSP01-5503	FORM	NC	28/04/26		3,73	0,00	.		0,00	16,8	1,5	N/D	
1	7	IACSP01-5503	FORM	NC	29/04/26		1,62	0,00	.		0,00	16,8	1,5	N/D	
1	8	IACSP01-5503	FORM	NC	29/04/26		2,80	0,00	.		0,00	16,8	1,5	N/D	
1	9	IACSP01-5503	FORM	NC	30/04/26		4,27	0,00	.		0,00	16,8	1,5	N/D	
1	10	IACSP01-5503	FORM	NC	30/04/26		1,23	0,00	.		0,00	16,8	1,5	N/D	
1	11	IACSP01-5503	FORM	NC	30/04/26		5,62	0,00	.		0,00	16,8	1,5	N/D	
1	12	IACSP01-5503	FORM	NC	30/04/26		1,69	0,00	.		0,00	16,8	1,5	N/D	
1	13	IACSP01-5503	FORM	NC	30/04/26		5,50	0,00	.		0,00	16,8	1,5	N/D	
1	14	IACSP01-5503	FORM	NC	30/04/26		1,62	0,00	.		0,00	16,8	1,5	N/D	
1	15	IACSP01-5503	FORM	NC	30/04/26		6,70	0,00	.		0,00	16,8	1,5	N/D	
1	16	IACSP01-5503	FORM	NC	30/04/26		4,35	0,00	.		0,00	16,8	1,5	N/D	
1	17	IACSP01-5503	FORM	NC	30/04/26		2,45	0,00	.		0,00	16,8	1,5	N/D	
1	18	IACSP01-5503	FORM	NC	30/04/26		1,60	0,00	.		0,00	16,8	1,5	N/D	
1	19	IACSP01-5503	FORM	NC	30/04/26		0,40	0,00	.		0,00	16,8	1,5	N/D	
Total/Média (1 / 129 · S.SEBASTIAO IV)							56,40	0,00			0,00				

N: 7713853.634
E: 335030.8915
LAT: −20°40'4.1716" (−20.66782545)
LONG: −46°35'2.6806" (−46.58407794)

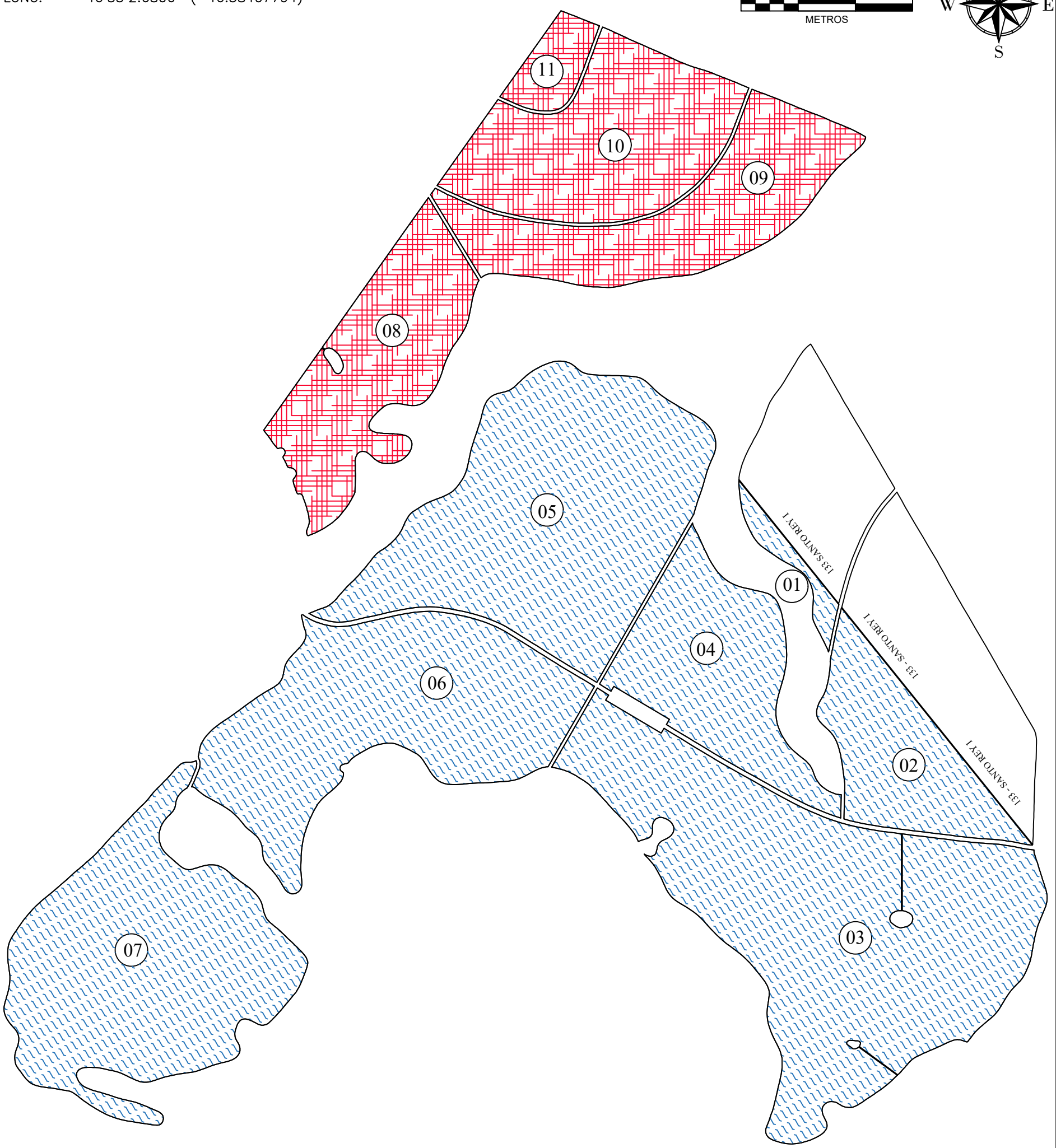

CTC - 9008
IAC SP 01-5503

TABELA DE VARIEDADE

VARIEDADE	ÁREA
CTC9008	77,23
IACSP01-5503	24,49
Total Geral	**101,72**

IPIRANGA AGROINDUSTRIAL

PROJETO: CADERNO DE MAPA 26'27	DATA: 21/05/2026	ESCALA: 1:5000	TOPÓGRAFO: CRISTIAN
FAZENDA: 130 - SANTO REY II	MUNICÍPIO: PASSOS - MG		ÁREA (ha): 101,72
PROPRIETÁRIO: IPIRANGA AGROINDUSTRIAL	UNIDADE: IPIRANGA PASSOS S.A.		

Caderno de Mapas

Bloco	Talhao	Variedade	Estágio de Corte	Amb. Prod.	Data Plantio	Data Último Corte	Área (ha)	Estimativas Área (ha)	Estimativas Finalid	Estimativas Produt.	Prod. Total	Dist.	Esp.	Tipo Corte	Experimento
1 · REG 1			**130 · SANTO REY II**					**IPIRANGA AGROINDUSTRIAL S.A**							
1	1	CTC9008	FORM	NC	24/03/26		0,73	0,00	.		0,00	39	1,5	N/D	
1	2	CTC9008	FORM	NC	24/03/26		5,24	0,00	.		0,00	39	1,5	N/D	
1	3	CTC9008	FORM	NC	28/03/26		21,88	0,00	.		0,00	39	1,5	N/D	
1	4	CTC9008	FORM	NC	18/03/26		6,89	0,00	.		0,00	39	1,5	N/D	
1	5	CTC9008	FORM	NC	24/03/26		15,87	0,00	.		0,00	39	1,5	N/D	
1	6	CTC9008	FORM	NC	28/03/26		12,90	0,00	.		0,00	39	1,5	N/D	
1	7	CTC9008	FORM	NC	25/03/26		13,72	0,00	.		0,00	39	1,5	N/D	
1	8	IACSP01-5503	FORM	NC	10/04/26		7,20	0,00	.		0,00	39	1,5	N/D	
1	9	IACSP01-5503	FORM	NC	11/04/26		7,59	0,00	.		0,00	39	1,5	N/D	
1	10	IACSP01-5503	FORM	NC	07/04/26		8,41	0,00	.		0,00	39	1,5	N/D	
1	11	IACSP01-5503	FORM	NC	07/04/26		1,29	0,00	.		0,00	39	1,5	N/D	
Total/Média (1 / 130 · SANTO REY II)							101,72	0,00			0,00				

N: 7713853.634
E: 335030.8915
LAT: −20°40'4.1716" (−20.66782545)
LONG: −46°35'2.6806" (−46.58407794)

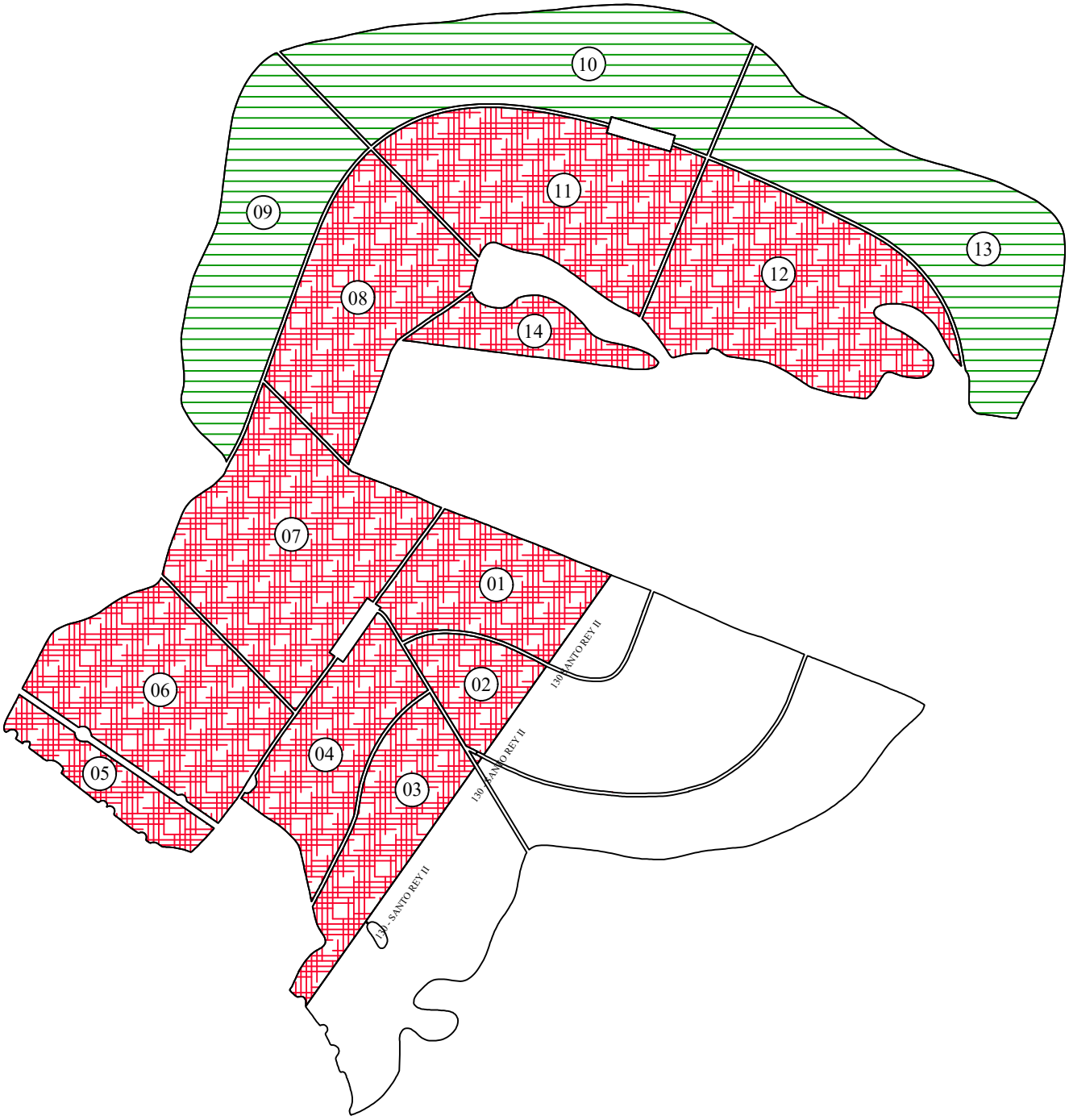

VIVEIRO
IAC SP 01-5503

TABELA DE VARIEDADE	
VARIEDADE	ÁREA
IACSP01-5503	63,59
VIVEIRO	28,43
Total Geral	**92,02**

IPIRANGA AGROINDUSTRIAL	PROJETO: CADERNO DE MAPA 26'27	DATA: 21/05/2026	ESCALA: 1:5000	TOPÓGRAFO: CRISTIAN
	FAZENDA: 131 - SANTO REY III	MUNICÍPIO: PASSOS - MG	ÁREA (ha): 92,02
	PROPRIETÁRIO: IPIRANGA AGROINDUSTRIAL	UNIDADE: IPIRANGA PASSOS S.A.	

Caderno de Mapas

Bloco	Talhao	Variedade	Estágio de Corte	Amb. Prod.	Data Plantio	Último Corte	Área (ha)	Estimativas Área (ha)	Finalid	Produt.	Prod. Total	Dist.	Esp.	Tipo Corte	Experimento
1 · REG 1			**131 · STO.REY III**				**IPIRANGA AGROINDUSTRIAL S.A**								
1	1	IACSP01-5503	FORM	NC	07/04/26		4,60	0,00	.		0,00	40	1,5	N/D	
1	2	IACSP01-5503	FORM	NC	07/04/26		2,14	0,00	.		0,00	40	1,5	N/D	
1	3	IACSP01-5503	FORM	NC	07/04/26		4,28	0,00	.		0,00	40	1,5	N/D	
1	4	IACSP01-5503	FORM	NC	06/04/26		4,65	0,00	.		0,00	40	1,5	N/D	
1	5	IACSP01-5503	FORM	NC	07/04/26		2,12	0,00	.		0,00	40	1,5	N/D	
1	6	IACSP01-5503	FORM	NC	07/04/26		7,84	0,00	.		0,00	40	1,5	N/D	
1	7	IACSP01-5503	FORM	NC	03/04/26		9,96	0,00	.		0,00	40	1,5	N/D	
1	8	IACSP01-5503	FORM	NC	07/04/26		7,25	0,00	.		0,00	40	1,5	N/D	
1	9	VIVEIRO	FORM	NC	02/04/26		8,09	0,00	.		0,00	40	1,5	N/D	
1	10	VIVEIRO	FORM	NC	01/04/26		9,96	0,00	.		0,00	40	1,5	N/D	
1	11	IACSP01-5503	FORM	NC	02/04/26		8,84	0,00	.		0,00	40	1,5	N/D	
1	12	IACSP01-5503	FORM	NC	02/04/26		9,76	0,00	.		0,00	40	1,5	N/D	
1	13	VIVEIRO	FORM	NC	01/04/26		10,38	0,00	.		0,00	40	1,5	N/D	
1	14	IACSP01-5503	FORM	NC	07/04/26		2,15	0,00	.		0,00	40	1,5	N/D	
Total/Média (1 / 131 · STO.REY III)							92,02	0,00			0,00				

N: 7726560.536
E: 337112.4145
LAT: −20°33'11.6296" (−20.55323044)
LONG: −46°33'46.5471" (−46.56292974)



CTC - 9006
RB 97-5201
IAC CTC 07-7207

TABELA DE VARIEDADE	
VARIEDADE	ÁREA
CTC9006	71,20
IACCTC07-7207	23,56
RB975375	6,22
Total Geral	**100,98**

IPIRANGA AGROINDUSTRIAL

PROJETO	DATA	ESCALA	TOPÓGRAFO
CADERNO DE MAPA 26'27	04/03/2026	1:5000	CRISTIAN
FAZENDA	**MUNICÍPIO**		**ÁREA (ha)**
132 - GOULART	SÃO J BATISTA DO GLÓRIA		100,98
PROPRIETÁRIO	**UNIDADE**		
DARLAN REIS BRITO	PASSOS MG		

Caderno de Mapas

Bloco	Talhao	Variedade	Estágio de Corte	Amb. Prod.	Data Plantio	Último Corte	Área (ha)	Estimativas Área (ha)	Finalid	Produt.	Prod. Total	Dist.	Esp.	Tipo Corte	Experimento
1 · REG 1			**132 · GOULART**				**IPIRANGA AGROINDUSTRIAL S.A**								
1	1	CTC9006	FORM	NC	16/02/26		5,42	0,00	.		0,00	11	1,5	N/D	
1	2	CTC9006	FORM	NC	16/02/26		6,76	0,00	.		0,00	11	1,5	N/D	
1	3	CTC9006	FORM	NC	18/02/26		6,93	0,00	.		0,00	11	1,5	N/D	
1	4	CTC9006	FORM	NC	17/02/26		4,50	0,00	.		0,00	11	1,5	N/D	
1	5	CTC9006	FORM	NC	15/02/26		3,88	0,00	.		0,00	11	1,5	N/D	
1	6	CTC9006	FORM	NC	16/01/26		3,67	0,00	.		0,00	11	1,5	N/D	
1	7	CTC9006	FORM	NC	16/01/26		4,87	0,00	.		0,00	11	1,5	N/D	
1	8	CTC9006	FORM	NC	16/01/26		2,42	0,00	.		0,00	11	1,5	N/D	
1	9	RB975375	FORM	NC	31/01/26		4,42	0,00	.		0,00	11	1,5	N/D	
1	10	IACCTC07-7207	FORM	NC	28/01/26		1,72	0,00	.		0,00	11	1,5	N/D	
1	10	RB975375	FORM	NC	28/01/26		1,80	0,00	.		0,00	11	1,5	N/D	
1	11	CTC9006	FORM	NC	18/02/26		4,92	0,00	.		0,00	11	1,5	N/D	
1	12	CTC9006	FORM	NC	18/02/26		0,42	0,00	.		0,00	11	1,5	N/D	
1	13	IACCTC07-7207	FORM	NC	22/01/26		1,01	0,00	.		0,00	11	1,5	N/D	
1	14	IACCTC07-7207	FORM	NC	15/01/26		4,40	0,00	.		0,00	11	1,5	N/D	
1	15	IACCTC07-7207	FORM	NC	14/01/26		2,49	0,00	.		0,00	11	1,5	N/D	
1	16	IACCTC07-7207	FORM	NC	14/01/26		1,60	0,00	.		0,00	11	1,5	N/D	
1	17	IACCTC07-7207	FORM	NC	16/01/26		1,42	0,00	.		0,00	11	1,5	N/D	
1	18	IACCTC07-7207	FORM	NC	16/01/26		1,84	0,00	.		0,00	11	1,5	N/D	
1	19	IACCTC07-7207	FORM	NC	17/01/26		5,47	0,00	.		0,00	11	1,5	N/D	
1	20	IACCTC07-7207	FORM	NC	17/01/26		2,22	0,00	.		0,00	11	1,5	N/D	
1	21	IACCTC07-7207	FORM	NC	22/01/26		1,39	0,00	.		0,00	11	1,5	N/D	
1	22	CTC9006	FORM	NC	18/02/26		2,41	0,00	.		0,00	11	1,5	N/D	
1	23	CTC9006	FORM	NC	15/01/26		14,04	0,00	.		0,00	11	1,5	N/D	
1	24	CTC9006	FORM	NC	16/01/26		1,69	0,00	.		0,00	11	1,5	N/D	
1	25	CTC9006	FORM	NC	16/01/26		8,40	0,00	.		0,00	11	1,5	N/D	
1	26	CTC9006	FORM	NC	16/01/26		0,35	0,00	.		0,00	11	1,5	N/D	
1	27	CTC9006	FORM	NC	15/01/26		0,52	0,00	.		0,00	11	1,5	N/D	
Total/Média (1 / 132 · GOULART)							100,98	0,00			0,00				

N: 7713853.634
E: 335030.8915
LAT: −20°40'4.1716" (−20.66782545)
LONG: −46°35'2.6806" (−46.58407794)

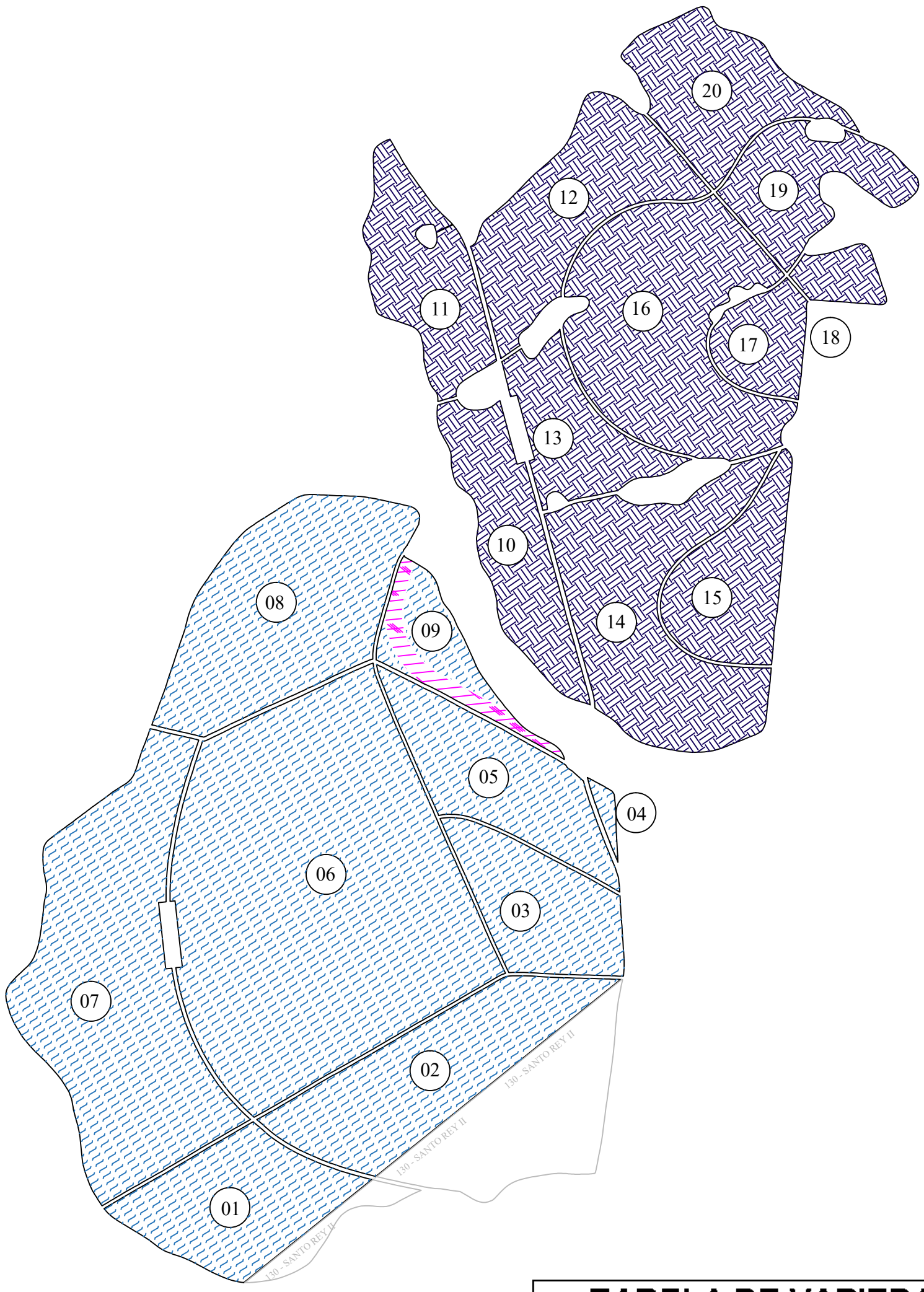

CTC -2994
CTC - 9008
CTC - 9006

TABELA DE VARIEDADE

VARIEDADE	ÁREA
CTC2994	0,91
CTC9006	47,11
CTC9008	64,19
Total Geral	**112,21**

IPIRANGA AGROINDUSTRIAL

PROJETO: CADERNO DE MAPA 26'27	DATA: 25/03/2026	ESCALA: 1:5000	TOPÓGRAFO: CRISTIAN
FAZENDA: 133 - SANTO REY I	MUNICÍPIO: PASSOS - MG		ÁREA (ha): 112,21
PROPRIETÁRIO: IPIRANGA AGROINDUSTRIAL	UNIDADE: IPIRANGA PASSOS S.A.		

Caderno de Mapas

Bloco	Talhao	Variedade	Estágio de Corte	Amb. Prod.	Data Plantio	Data Último Corte	Área (ha)	Estimativas Área (ha)	Estimativas Finalid	Estimativas Produt.	Prod. Total	Dist.	Esp.	Tipo Corte	Experimento
1 · REG 1			**133 · SANTO REY I**					**IPIRANGA AGROINDUSTRIAL S.A**							
1	1	CTC9008	FORM	NC	09/03/26		4,84	0,00	.		0,00	38	1,5	N/D	
1	2	CTC9008	FORM	NC	08/03/26		6,34	0,00	.		0,00	38	1,5	N/D	
1	3	CTC9008	FORM	NC	09/03/26		3,88	0,00	.		0,00	38	1,5	N/D	
1	4	CTC9008	FORM	NC	05/03/26		0,22	0,00	.		0,00	38	1,5	N/D	
1	5	CTC9008	FORM	NC	09/03/26		4,60	0,00	.		0,00	38	1,5	N/D	
1	6	CTC9008	FORM	NC	07/03/26		21,69	0,00	.		0,00	38	1,5	N/D	
1	7	CTC9008	FORM	NC	05/03/26		12,66	0,00	.		0,00	38	1,5	N/D	
1	8	CTC9008	FORM	NC	19/03/26		8,59	0,00	.		0,00	38	1,5	N/D	
1	9	CTC2994	FORM	NC	19/03/26		0,91	0,00	.		0,00	38	1,5	N/D	
1	9	CTC9008	FORM	NC	19/03/26		1,37	0,00	.		0,00	38	1,5	N/D	
1	10	CTC9006	FORM	NC	09/03/26		4,12	0,00	.		0,00	38	1,5	N/D	
1	11	CTC9006	FORM	NC	09/03/26		3,96	0,00	.		0,00	38	1,5	N/D	
1	12	CTC9006	FORM	NC	09/03/26		5,46	0,00	.		0,00	38	1,5	N/D	
1	13	CTC9006	FORM	NC	08/03/26		3,01	0,00	.		0,00	38	1,5	N/D	
1	14	CTC9006	FORM	NC	03/03/26		7,88	0,00	.		0,00	38	1,5	N/D	
1	15	CTC9006	FORM	NC	03/03/26		3,54	0,00	.		0,00	38	1,5	N/D	
1	16	CTC9006	FORM	NC	03/03/26		8,89	0,00	.		0,00	38	1,5	N/D	
1	17	CTC9006	FORM	NC	04/03/26		1,87	0,00	.		0,00	38	1,5	N/D	
1	18	CTC9006	FORM	NC	04/03/26		0,93	0,00	.		0,00	38	1,5	N/D	
1	19	CTC9006	FORM	NC	04/03/26		3,21	0,00	.		0,00	38	1,5	N/D	
1	20	CTC9006	FORM	NC	04/03/26		4,24	0,00	.		0,00	38	1,5	N/D	
Total/Média (1 / 133 · SANTO REY I)							112,21	0,00			0,00				

N: 7713853.634
E: 335030.8915
LAT: −20°40'4.1716" (−20.66782545)
LONG: −46°35'2.6806" (−46.58407794)

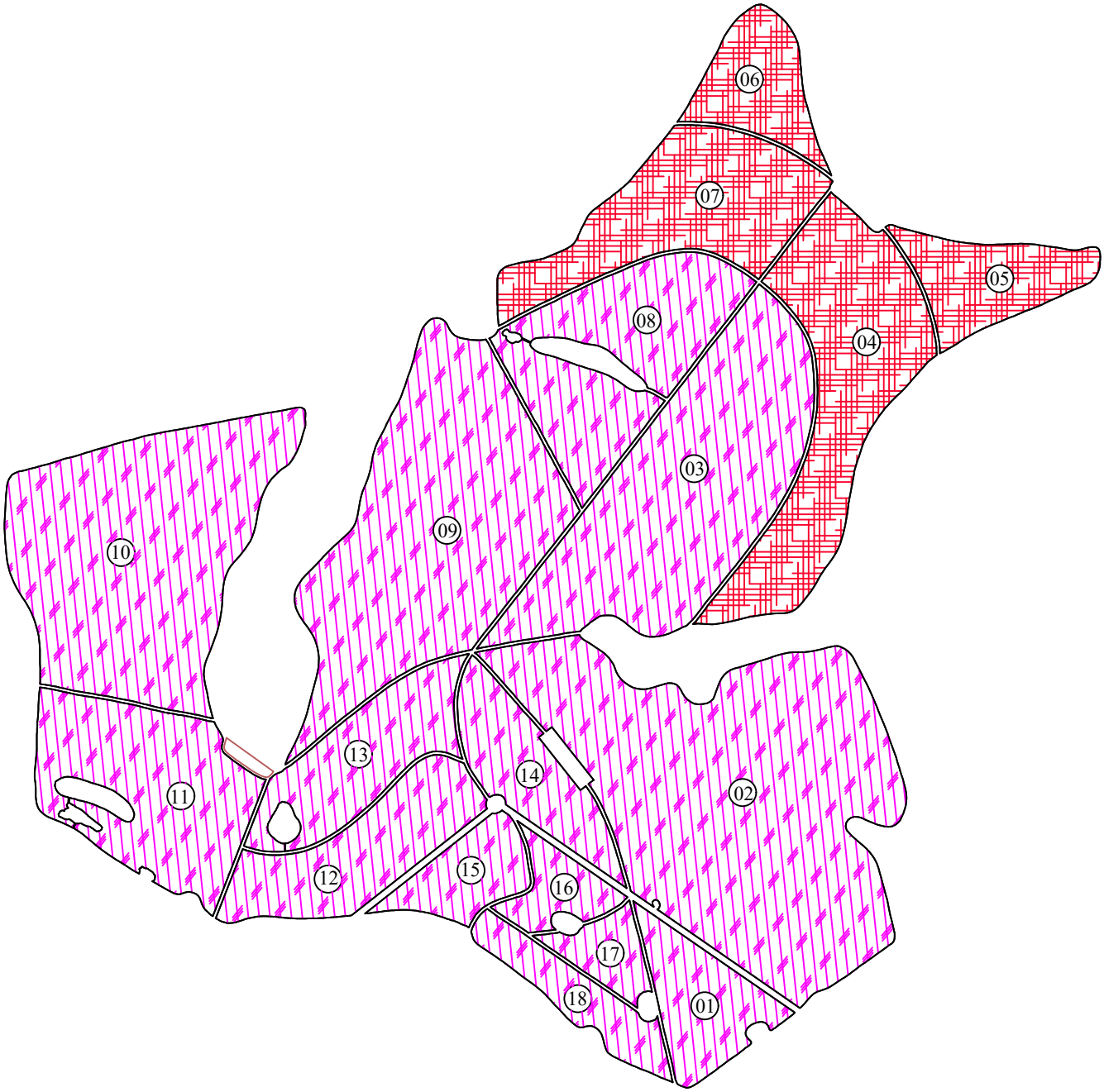

CTC -2994
IAC SP 01-5503

TABELA DE VARIEDADE	
VARIEDADE	ÁREA
CTC2994	90,69
IACSP01-5503	19,94
Total Geral	**110,63**

IPIRANGA AGROINDUSTRIAL

PROJETO: CADERNO DE MAPA 25'26	DATA: 21/05/2026	ESCALA: 1:5000	TOPÓGRAFO: CRISTIAN
FAZENDA: 134 - SANTO REY IV	MUNICÍPIO: PASSOS - MG		ÁREA (ha): 110,63
PROPRIETÁRIO: IPIRANGA AGROINDUSTRIAL	UNIDADE: IPIRANGA PASSOS S.A.		

Caderno de Mapas

Bloco	Talhao	Variedade	Estágio de Corte	Amb. Prod.	Data Plantio	Data Último Corte	Área (ha)	Estimativas Área (ha)	Estimativas Finalid	Estimativas Produt.	Prod. Total	Dist.	Esp.	Tipo Corte	Experimento
1 · REG 1			**134 · STO.REY IV**				**IPIRANGA AGROINDUSTRIAL S.A**								
1	1	CTC2994	FORM	NC	21/04/26		2,78	0,00	.		0,00	42	1,5	N/D	
1	2	CTC2994	FORM	NC	17/04/26		19,23	0,00	.		0,00	42	1,5	N/D	
1	3	CTC2994	FORM	NC	15/04/26		11,54	0,00	.		0,00	42	1,5	N/D	
1	4	IACSP01-5503	FORM	NC	14/04/26		8,21	0,00	.		0,00	42	1,5	N/D	
1	5	IACSP01-5503	FORM	NC	11/04/26		2,89	0,00	.		0,00	42	1,5	N/D	
1	6	IACSP01-5503	FORM	NC	14/04/26		2,61	0,00	.		0,00	42	1,5	N/D	
1	7	IACSP01-5503	FORM	NC	14/04/26		6,23	0,00	.		0,00	42	1,5	N/D	
1	8	CTC2994	FORM	NC	15/04/26		6,66	0,00	.		0,00	42	1,5	N/D	
1	9	CTC2994	FORM	NC	17/04/26		13,25	0,00	.		0,00	42	1,5	N/D	
1	10	CTC2994	FORM	NC	18/04/26		12,73	0,00	.		0,00	42	1,5	N/D	
1	11	CTC2994	FORM	NC	20/04/26		6,62	0,00	.		0,00	42	1,5	N/D	
1	12	CTC2994	FORM	NC	18/04/26		4,33	0,00	.		0,00	42	1,5	N/D	
1	13	CTC2994	FORM	NC	18/04/26		3,90	0,00	.		0,00	42	1,5	N/D	
1	14	CTC2994	FORM	NC	20/04/26		3,10	0,00	.		0,00	42	1,5	N/D	
1	15	CTC2994	FORM	NC	20/04/26		1,98	0,00	.		0,00	42	1,5	N/D	
1	16	CTC2994	FORM	NC	20/04/26		1,34	0,00	.		0,00	42	1,5	N/D	
1	17	CTC2994	FORM	NC	20/04/26		1,19	0,00	.		0,00	42	1,5	N/D	
1	18	CTC2994	FORM	NC	20/04/26		2,04	0,00	.		0,00	42	1,5	N/D	
Total/Média (1 / 134 · STO.REY IV)							110,63	0,00			0,00				

N: 7713853.634
E: 335030.8915
LAT: −20°40'4.1716" (−20.66782545)
LONG: −46°35'2.6806" (−46.58407794)

50.0 0 50.0 100.0
METROS

N
W E
S

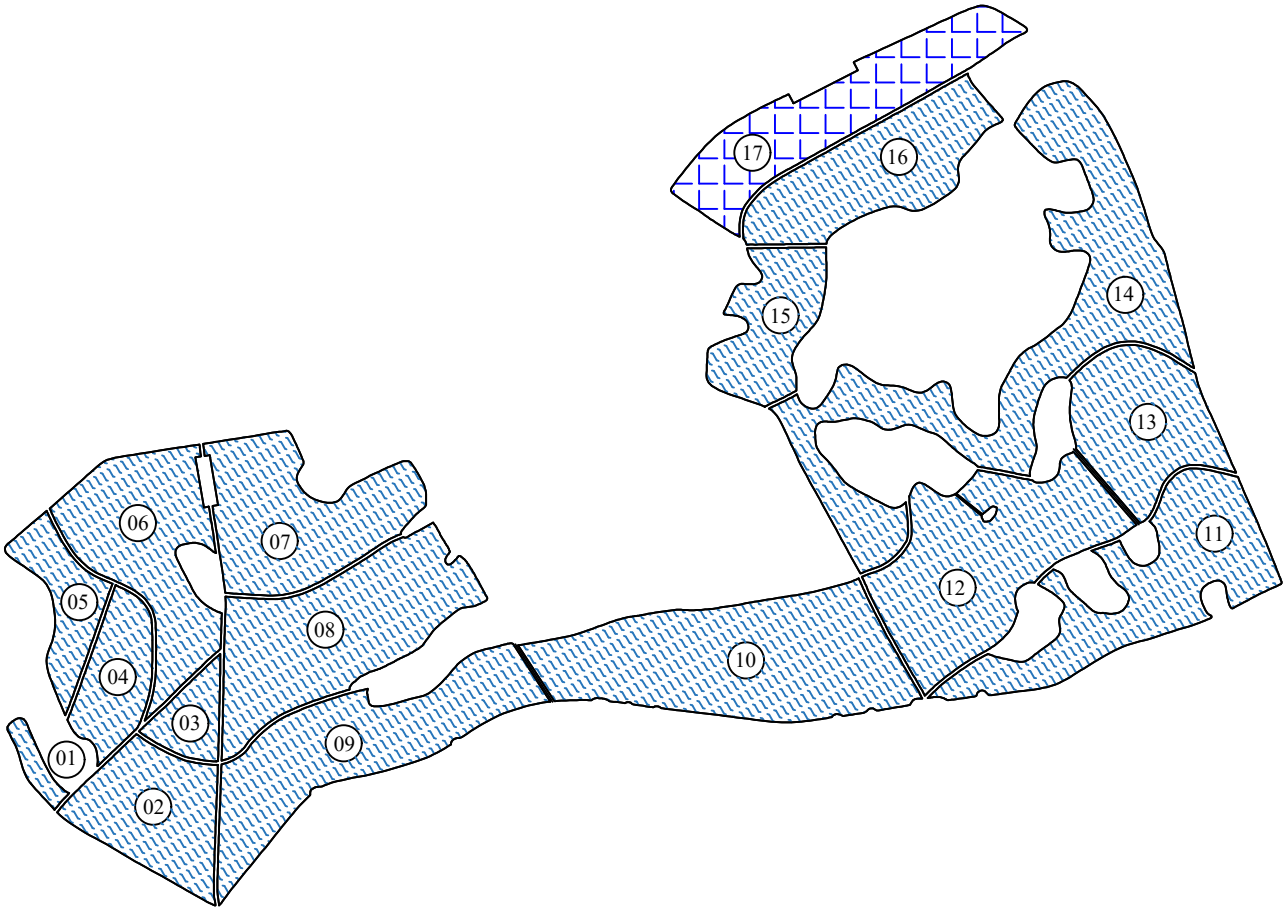

TABELA DE VARIEDADE	
VARIEDADE	ÁREA
CTC2	4,22
CTC9008	61,86
Total Geral	**66,08**

CTC - 2
CTC - 9008

IPIRANGA AGROINDUSTRIAL

PROJETO: CADERNO DE MAPA 26'27	DATA: 21/05/2026	ESCALA: 1:5000	TOPÓGRAFO: CRISTIAN
FAZENDA: 135 - BRAGANÇA	MUNICÍPIO: PASSOS - MG		ÁREA (ha): 66,08
PROPRIETÁRIO: IPIRANGA AGROINDUSTRIAL	UNIDADE: IPIRANGA PASSOS S.A.		

Caderno de Mapas

Bloco	Talhao	Variedade	Estágio de Corte	Amb. Prod.	Data Plantio	Data Último Corte	Área (ha)	Estimativas Área (ha)	Estimativas Finalid	Estimativas Produt.	Prod. Total	Dist.	Esp.	Tipo Corte	Experimento
1 · REG 1			**135 · BRAGANÇA**				**IPIRANGA AGROINDUSTRIAL S.A**								
1	1	CTC9008	FORM	NC	11/04/26		0,36	0,00	.		0,00	31	1,5	N/D	
1	2	CTC9008	FORM	NC	11/04/26		2,96	0,00	.		0,00	31	1,5	N/D	
1	3	CTC9008	FORM	NC	13/04/26		0,89	0,00	.		0,00	31	1,5	N/D	
1	4	CTC9008	FORM	NC	16/04/26		1,73	0,00	.		0,00	31	1,5	N/D	
1	5	CTC9008	FORM	NC	16/04/26		1,53	0,00	.		0,00	31	1,5	N/D	
1	6	CTC9008	FORM	NC	15/04/26		4,21	0,00	.		0,00	31	1,5	N/D	
1	7	CTC9008	FORM	NC	15/04/26		4,24	0,00	.		0,00	31	1,5	N/D	
1	8	CTC9008	FORM	NC	14/04/26		5,42	0,00	.		0,00	31	1,5	N/D	
1	9	CTC9008	FORM	NC	13/04/26		5,04	0,00	.		0,00	31	1,5	N/D	
1	10	CTC9008	FORM	NC	13/04/26		7,01	0,00	.		0,00	31	1,5	N/D	
1	11	CTC9008	FORM	NC	11/04/26		4,87	0,00	.		0,00	31	1,5	N/D	
1	12	CTC9008	FORM	NC	17/04/26		5,88	0,00	.		0,00	31	1,5	N/D	
1	13	CTC9008	FORM	NC	17/04/26		3,37	0,00	.		0,00	31	1,5	N/D	
1	14	CTC9008	FORM	NC	18/04/26		8,20	0,00	.		0,00	31	1,5	N/D	
1	15	CTC9008	FORM	NC	20/04/26		2,31	0,00	.		0,00	31	1,5	N/D	
1	16	CTC9008	FORM	NC	20/04/26		3,84	0,00	.		0,00	31	1,5	N/D	
1	17	CTC2	FORM	NC	22/04/26		4,22	0,00	.		0,00	31	1,5	N/D	
Total/Média (1 / 135 · BRAGANÇA)							66,08	0,00			0,00				

N: 7713853.634
E: 335030.8915
LAT: −20°40'4.1716" (−20.66782545)
LONG: −46°35'2.6806" (−46.58407794)

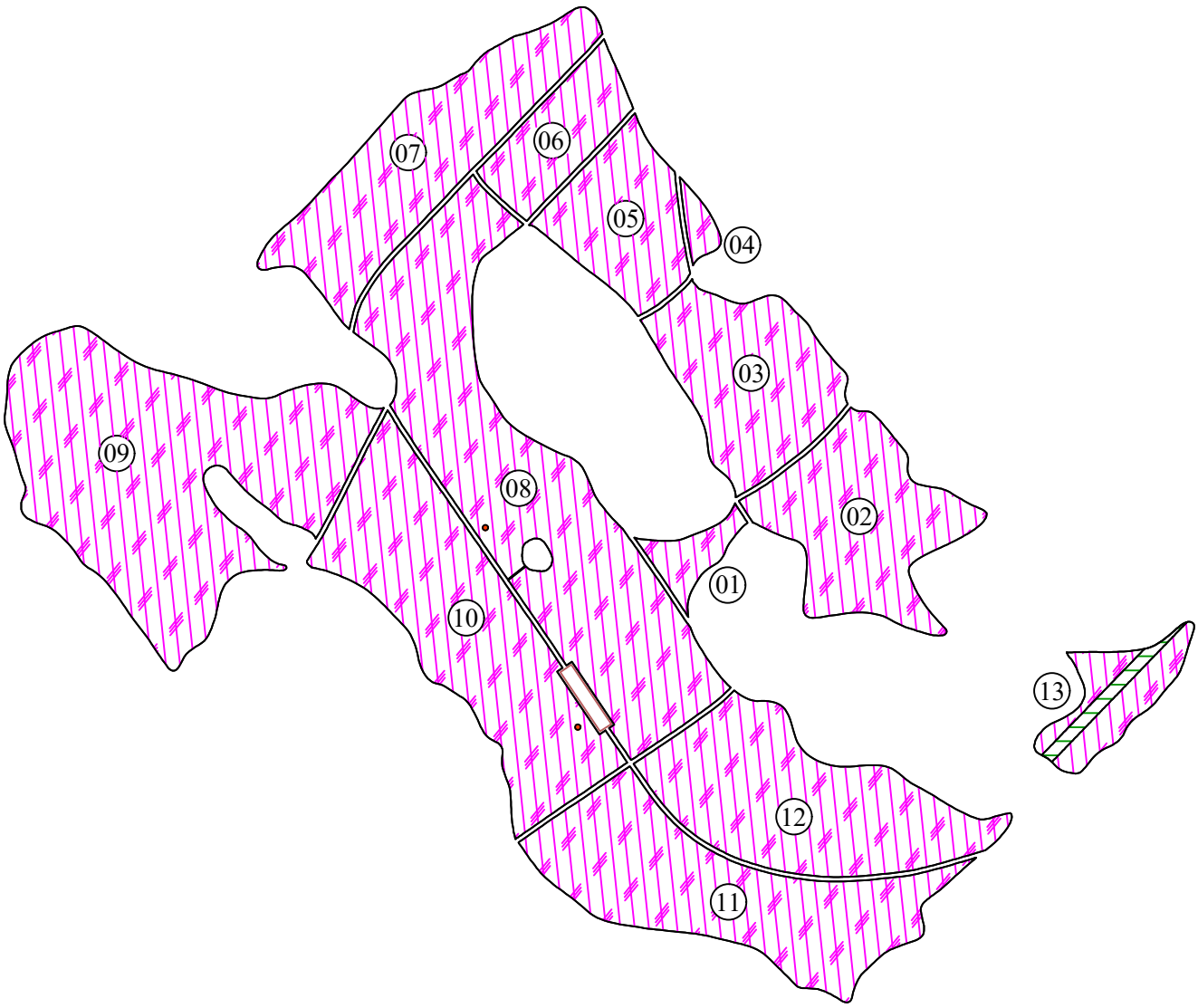

VIVEIRO
CTC -2994

TABELA DE VARIEDADE	
VARIEDADE	ÁREA
CTC2994	47,94
VIVEIRO	0,25
Total Geral	**48,19**

IPIRANGA AGROINDUSTRIAL

PROJETO: CADERNO DE MAPA 26'27	DATA: 21/05/2026	ESCALA: 1:5000	TOPÓGRAFO: CRISTIAN
FAZENDA: 136 - SÃO JOÃO DA BOCAINA	MUNICÍPIO: PASSOS - MG		ÁREA (ha): 48,19
PROPRIETÁRIO: IPIRANGA AGROINDUSTRIAL	UNIDADE: IPIRANGA PASSOS S.A.		

Caderno de Mapas

Bloco	Talhao	Variedade	Estágio de Corte	Amb. Prod.	Data Plantio	Data Último Corte	Área (ha)	Estimativas Área (ha)	Estimativas Finalid	Estimativas Produt.	Prod. Total	Dist.	Esp.	Tipo Corte	Experimento
1 · REG 1			**136 · S.J.DA BOCAINA**				**IPIRANGA AGROINDUSTRIAL S.A**								
1	1	CTC2994	FORM	NC	29/04/26		0,51	0,00	.		0,00	16,5	1,5	N/D	
1	2	CTC2994	FORM	NC	28/04/26		3,48	0,00	.		0,00	16,5	1,5	N/D	
1	3	CTC2994	FORM	NC	23/04/26		3,17	0,00	.		0,00	16,5	1,5	N/D	
1	4	CTC2994	FORM	NC	23/04/26		0,22	0,00	.		0,00	16,5	1,5	N/D	
1	5	CTC2994	FORM	NC	23/04/26		2,17	0,00	.		0,00	16,5	1,5	N/D	
1	6	CTC2994	FORM	NC	23/04/26		1,50	0,00	.		0,00	16,5	1,5	N/D	
1	7	CTC2994	FORM	NC	28/04/26		4,08	0,00	.		0,00	16,5	1,5	N/D	
1	8	CTC2994	FORM	NC	23/04/26		8,15	0,00	.		0,00	16,5	1,5	N/D	
1	9	CTC2994	FORM	NC	22/04/26		8,41	0,00	.		0,00	16,5	1,5	N/D	
1	10	CTC2994	FORM	NC	22/04/26		5,62	0,00	.		0,00	16,5	1,5	N/D	
1	11	CTC2994	FORM	NC	22/04/26		4,98	0,00	.		0,00	16,5	1,5	N/D	
1	12	CTC2994	FORM	NC	23/04/26		4,62	0,00	.		0,00	16,5	1,5	N/D	
1	13	CTC2994	FORM	NC	25/04/26		1,03	0,00	.		0,00	16,5	1,5	N/D	
1	13	VIVEIRO	FORM	NC	25/04/26		0,25	0,00	.		0,00	16,5	1,5	N/D	
Total/Média (1 / 136 · S.J.DA BOCAINA)							48,19	0,00			0,00				

N: 7713853.634
E: 335030.8915
LAT: −20°40'4.1716" (−20.66782545)
LONG: −46°35'2.6806" (−46.58407794)

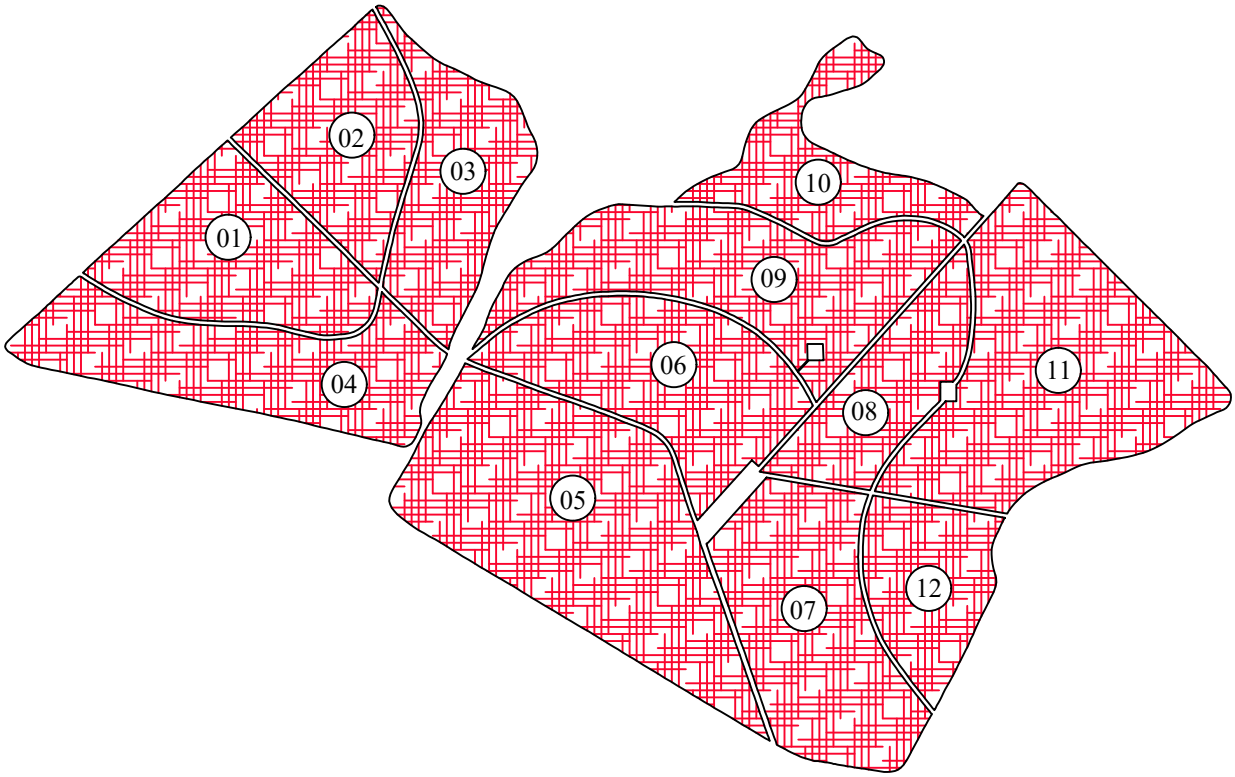

TABELA DE VARIENDADE	
VARIEDADE	ÁREA
IACSP01-5503	51,32
TOTAL	**51,32**

IAC SP 01-5503

IPIRANGA AGROINDUSTRIAL

PROJETO: CADERNO DE MAPA 26'27	DATA: 06/03/2026	ESCALA: 1:5000	TOPÓGRAFO: CRISTIAN
FAZENDA: 137 - CAVAQUINHO	MUNICÍPIO: PASSOS - MG		ÁREA (ha): 51,32
PROPRIETÁRIO: SUELY LEMOS	UNIDADE: IPIRANGA PASSOS S.A.		

Caderno de Mapas

Bloco	Talhao	Variedade	Estágio de Corte	Amb. Prod.	Data Plantio	Data Último Corte	Área (ha)	Estimativas Área (ha)	Estimativas Finalid	Estimativas Produt.	Prod. Total	Dist.	Esp.	Tipo Corte	Experimento
1 · REG 1			**137 · CAVAQUINHO**				**IPIRANGA AGROINDUSTRIAL S.A**								
1	1	IACSP01-5503	FORM	NC	13/01/26		3,84	0,00	.		0,00	50	1,5	N/D	
1	2	IACSP01-5503	FORM	NC	13/01/26		3,22	0,00	.		0,00	50	1,5	N/D	
1	3	IACSP01-5503	FORM	NC	13/01/26		3,21	0,00	.		0,00	50	1,5	N/D	
1	4	IACSP01-5503	FORM	NC	13/01/26		4,48	0,00	.		0,00	50	1,5	N/D	
1	5	IACSP01-5503	FORM	NC	13/01/26		7,82	0,00	.		0,00	50	1,5	N/D	
1	6	IACSP01-5503	FORM	NC	13/01/26		4,47	0,00	.		0,00	50	1,5	N/D	
1	7	IACSP01-5503	FORM	NC	13/01/26		4,82	0,00	.		0,00	50	1,5	N/D	
1	8	IACSP01-5503	FORM	NC	13/01/26		2,49	0,00	.		0,00	50	1,5	N/D	
1	9	IACSP01-5503	FORM	NC	13/01/26		5,13	0,00	.		0,00	50	1,5	N/D	
1	10	IACSP01-5503	FORM	NC	13/01/26		2,46	0,00	.		0,00	50	1,5	N/D	
1	11	IACSP01-5503	FORM	NC	13/01/26		6,97	0,00	.		0,00	50	1,5	N/D	
1	12	IACSP01-5503	FORM	NC	13/01/26		2,41	0,00	.		0,00	50	1,5	N/D	
Total/Média (1 / 137 · CAVAQUINHO)							51,32	0,00			0,00				